표준품셈 제5호

국토계획 표준품셈

(국토 및 도시계획, 조경 및 관광레저계획)

2015. 7

한국엔지니어링협회

표준품셈 제5호

국토계획 표준품셈

(국토 및 도시계획, 조경 및 관광레저계획)

한 국 기 술 용 역 협 회 제 정 : 한기협 510-114 (1982. 05. 15)
과 학 기 술 처 장 관 승 인 : 기관 622.1 1-4610 (1983. 4. 26)
한 국 엔 지 니 어 링 진 흥 협 회 : 이사회의결 (1993. 12. 03 전면개정)
한 국 엔 지 니 어 링 진 흥 협 회 : 이사회의결 (2000. 12. 11 전면개정)
한 국 엔 지 니 어 링 진 흥 협 회 : 이사회의결 (2007. 11. 09 일부개정)
한 국 엔 지 니 어 링 협 회 : 이사회의결 (2014. 10. 31 전면개정)
한 국 엔 지 니 어 링 협 회 : 이사회의결 (2015. . 일부개정)

2015. 7

한국엔지니어링협회

< 목 차 >

제1장 총 칙

제1절 서문 ····· 1
제2절 품셈구성 ····· 5
제3절 품셈 산정기준 ····· 6
제4절 품셈 운영기준 ····· 13

제2장 국토 및 지역계획

제1절 국토종합계획 ····· 19
제2절 부문별계획 ····· 22
제3절 도 종합계획 ····· 24
제4절 지역계획 ····· 27
제5절 농·산·어촌계획 ····· 36

제3장 도시계획

제1절 광역도시계획 ····· 45
제2절 도시·군기본계획 ····· 53
제3절 도시·군관리계획 ····· 60
제4절 도시(지역)교통계획 ····· 73
제5절 지형도면고시계획 ····· 78
제6절 단계별집행계획 ····· 84
제7절 개발제한구역 관리계획 ····· 91
제8절 도시계획 기초조사 ····· 97
제9절 성장관리방안 ····· 104
제10절 개발행위허가 ····· 115
제11절 도시방재계획 ····· 121
제12절 저탄소 녹색도시계획 ····· 128

제4장 도시설계

제1절 지구단위계획 ····· 135
제2절 마을만들기 ····· 147

제5장 도시개발

제1절 도시개발구역 지정 ····· 153
제2절 환지방식 개발계획 ····· 159
제3절 주택단지 개발계획 ····· 176
제4절 산업단지 개발계획 ····· 185
제5절 「캠퍼스」계획 ····· 194
제6절 유통(물류)단지 개발계획 ····· 199

제6장 도시재생

제1절 도시재생계획 ····· 209
제2절 재정비촉진계획 ····· 224
제3절 도시 및 주거환경정비계획 ····· 239
제4절 리모델링 기본계획 ····· 277

제7장 도시경관

제1절 도시경관계획 ····· 283
제2절 지구경관계획 ····· 293
제3절 사회기반시설사업 등의 경관심의 ····· 312

제8장 도시평가

제1절 국토계획평가 ····· 319
제2절 토지적성평가 ····· 324
제3절 재해취약성분석 ····· 330

제4절 환경성검토 ····· 337
제5절 교통성검토 ····· 342
제6절 경관성검토 ····· 346
제7절 사전재해영향성검토 ····· 352
제8절 교육환경평가 ····· 369
제9절 도시계획지속가능성평가 ····· 374
제10절 환경평가검증에 관한 업무(도시·군기본계획수립을 위한) ····· 379

제9장 공원·관광지·유원지·체육시설 등의 계획

제1절 공원녹지 기본계획 ····· 385
제2절 도시녹화계획 ····· 393
제3절 공원계획 ····· 399
제4절 관광지 · 유원지 · 휴양지 · 체육시설지 계획 ····· 417
제5절 문화재 사적지 계획 ····· 429

제10장 조경특화계획

제1절 도로조경계획 ····· 437
제2절 시가지 광장과 건축관련 공간계획 ····· 444
제3절 단지조경계획 ····· 451
제4절 환경·생태복원계획 ····· 459
제5절 개발제한구역 조경설계검토 도서 작성 ····· 467

제11장 사업관리

제1절 사업타당성 조사분석업무 ····· 471
제2절 농지전용 ····· 480
제3절 산지전용 ····· 486
제4절 총괄계획관리(PPM : Project Planning Management) ····· 492
제5절 계획관리 ····· 495

제6절 사후관리계획 ····· 498
제7절 도시계획 퍼실리테이션(Facilitation) ····· 503

제1장 총 칙

제1절 서문
제2절 품셈구성
제3절 품셈 산정기준
제4절 품셈 운영기준

제1절 서문

○ 국토계획은 인간정주환경의 “틀”을 마련하는 제요소를 상호 관련시켜 보다 기능적이고 경제적이며 아름다운 환경을 조성함에 있어서 국토이용, 개발 및 보전을 통한 고도의 인간정주생활환경의 질을 창조하는 종합과학과 예술적 기술을 담당하는 분야이다.

○ 이러한 국토계획분야는 그동안의 전문분야별 독립적 고유영역의 업무 참여를 넘어서 새로운 변화를 창조하고 진화해야 하며 새로운 공익적 가치를 창출해야 한다. 즉, 국토계획분야와 관련된 폭넓은 전문분야와 보다 발전적이고 협력적인 관계를 통해 문화·관광레저, 경관·디자인 등 삶의 질 향상, 새로운 산업의 가치창출이 가능하고 보다 안전하고 쾌적한 국토환경조성, 시민이 참여하고 바라는 국토공간디자인을 창출하고 이를 지속적으로 관리할 수 있도록 하여야 한다.

○ 이상과 같은 국토계획의 시행이 보다 효과적으로 수행되기 위해서 국토계획 품셈은

- 첫째, 국가직무능력표준(NCS : National Competency Standards)에서 제시된 국토계획분야의 직무를 체계화하고 구체화하여 실현성을 높이며 새로운 패러다임과 공익적 가치를 창출할 수 있는 국토계획콘텐츠를 제공하고,
- 둘째, 적정한 품셈마련과 품셈운영기준을 통해 신의성실의 원칙과 당사자 대등의 원칙을 준수하는 직무문화를 정착시키고, 보다 투명하고 명확한 산정기준을 통해 실질적인 품셈운영이 될 수 있도록 하며,
- 셋째, 국토계획 표준품셈의 적용범위는 공간적으로는 통일의 국토공간을 포함하고 시간적으로는 기획부터 준공까지 입체적 공간디자인이 가능하도록 하는 내용으로 구성된다.

○ 특히, 본 품셈의 총칙에서는 엔지니어링활동의 정의와 업무범위 및 국토계획분야의 업무과정, 품 구성과 적용 등을 기술하고 단계별 계획 및 설계에 관련된 산정 품을 각 항(項)으로 구분하여 기술함으로서 품셈 활용에 용이성을 높이고자 하였다.

1-1 적용기준

1-1-1 목적

○ 국가, 지방자치단체, 정부투자기관, 민간기관(단체) 및 개인 등(이하 “발주자”이라 한다)이 기술사법시행령 제2조에 정한 기술사 직무분류 중 건설부문 도시계획과 조경 전문분야의 엔지니어링사업에 대하여 엔지니어링산업 진흥법에 의한 엔지니어링사업자 또는 기술사법에 의한 기술사사무소 개설등록업체(이하 “엔지니어링사업자”라 한다)에게 위탁할 경우 기술제공의 질적인 보장과 엔지니어링사업대가의 적정 산정을 위한 기준을 제공함으로써 국가산업 발전에 이바지하는 데 있다.

1-1-2 적용범위

○ 발주자 등이 도시계획과 조경 전문분야의 엔지니어링사업을 엔지니어링사업자에게 위탁할 경우 적정업무와 대가산정에 본 표준품셈을 적용한다.

1-1-3 적용의 일반원칙

○ 엔지니어링사업을 발주하는 발주자 등과 이를 수행하는 엔지니어링사업자간에는 「민법」등 관계 법령에서 인정하고 있는 신의성실의 원칙과 당사자 대등의 원칙 등을 기초로 하여 본 표준품셈을 해석하고 적용한다.

※ 민법 제2조(신의성실)
①권리의 행사와 의무의 이행은 신의에 좇아 성실히 하여야 한다.
②권리는 남용하지 못한다.

※ 건설산업기본법 제22조(건설공사에 관한 도급계약의 원칙)
①건설공사에 관한 도급계약(하도급계약을 포함)의 당사자는 대등한 입장에서 합의에 따라 공정하게 계약을 체결하고, 신의에 따라 성실하게 계약을 이행하여야 한다.
⑤건설공사 도급계약의 내용이 당사자 일방에게 현저하게 불공정한 경우로서 다음 각 호의 어느 하나에 해당하는 경우에는 그 부분에 한정하여 무효로 한다.
1. 계약체결 이후 설계변경, 경제상황의 변동에 따라 발생하는 계약금액의 변경을 상당한 이유 없이 인정하지 아니하거나 그 부담을 상대방에게 전가하는 경우
2. 계약체결 이후 공사내용의 변경에 따른 계약기간의 변경을 상당한 이유 없이 인정하지 아니하거나 그 부담을 상대방에게 전가하는 경우
3. 도급계약의 형태, 건설공사의 내용 등 관련된 모든 사정에 비추어 계약체결 당시 예상하기 어려운 내용에 대하여 상대방에게 책임을 전가하는 경우
4. 계약내용에 대하여 구체적인 정함이 없거나 당사자 간 이견이 있을 경우 계약내용을 일방의 의사에 따라 정함으로써 상대방의 정당한 이익을 침해한 경우
5. 계약불이행에 따른 당사자의 손해배상책임을 과도하게 경감하거나 가중하여 정함으로써 상대방의 정당한 이익을 침해한 경우
6. 「민법」등 관계 법령에서 인정하고 있는 상대방의 권리를 상당한 이유 없이 배제하거나 제한하는 경우

○ 본 표준품셈의 적용 및 운용상의 일반적인 사항은 엔지니어링산업 진흥법과 엔지니어링사업대가의 기준을 적용하며, 필요시 엔지니어링사업대가 및 계약금액을 조정한다.

※ 엔지니어링산업 진흥법 제31조(엔지니어링사업의 대가 기준 등)
①발주청은 엔지니어링사업자와 엔지니어링사업의 계약을 체결한 때에는 적정한 엔지니어링사업의 대가를 지급하여야 한다.
※ 엔지니어링사업대가의 기준
- 제5조(대가의 조정) : 물가 변동, 업무 변경, 사업기간 및 사업규모 변경 등
- 제17조(추가업무비용) : 주민의견 수렴 및 각종 인·허가에 필요한 서류 작성 등
※ 국가를 당사자로 하는 계약에 관한 법률 제19조(물가변동 등에 따른 계약금액 조정)
- 시행령 제65조(설계변경으로 인한 계약금액의 조정),
- 시행령 제66조(기타 계약내용의 변경으로 인한 계약금액의 조정)
※ 지방자치단체를 당사자로 하는 계약에 관한 법률 제22조(물가변동 등에 따른 계약금액의 조정)
- 시행령 제73조(물가변동으로 인한 계약금액의 조정)
- 시행령 제74조(설계변경으로 인한 계약금액의 조정)
- 시행령 제75조(그 밖에 계약내용의 변경으로 인한 계약금액의 조정)

○ 본 표준품셈은 엔지니어링기술자의 구분과 자료제공전제, 지역이나 과업특성 및 기타 조건에 따라 조정하여 적용할 수 있다.

○ 본 표준품셈과 연관되어 추진되는 기본설계와 실시설계에 대한 품은 "엔지니어링사업대가의 기준" 중 공사비요율에 의한 방식과 별표 1 (건설부문의 요율)을 적용하되 동 기준 제15조(요율의 조정)에 따라 다음과 같은 조건 등을 참작하여 조정할 수 있다.

1) 계획 및 설계의 난이도

2) 비교설계의 유무

3) 도면, 기타 자료작성의 복잡성

4) 제출자료의 수량

○ 본 표준품셈이 적용되는 공정범위는 조사, 분석, 계획안 구상 및 분석평가, 계획안의 확정 등 과업에 명시된 일련의 작업과 기술협의(공청회, 공람, 의회보고 등)를 거치는 확정계획안 작성과정에 한정하는 것이며, 계획안 확정 후의 정책변경, 시대적 상황변화 및 인·허가과정에서의 대폭적인 수정 등에 의한 계획안의 재작성 등은 본 표준품셈 제1장 제4절 품셈운영기준에 따라 별도의 엔지니어링사업대가를 지불하여야 한다.

1-2 엔지니어링 관련 용어의 정의

○ 본 품셈에서 사용하는 용어의 뜻은 다음과 같다.

1-2-1 엔지니어링

○ 엔지니어링(ENGINEERING)이라 함은 여러 분야에 걸친 인간의 지혜를 결집·통합하여 일정한 과제를 달성하는 과학기술적인 활동으로서 과학의 원리 그 자체보다 과학을 실용화하여 인간의 편의를 도모하는 기술로써,

1) 인간의 이용 및 편익을 위한 합목적성을 가지며,

2) 과학 그 자체보다도 과학을 실제로 응용하는 실용적인 기술이라 할 수 있다.

1-2-2 엔지니어링활동

○ 본 표준품셈상의 엔지니어링활동이라 함은 국내·외에서 추진되고 있는 엔지니어링 관련 사업 및 활동과 그에 대한 사업관리를 포함하며, 엔지니어링산업 진흥법의 규정에 의한 엔지니어링활동을 준용한다.

※ 엔지니어링산업 진흥법, 동법 시행령 제2조(정의)
"엔지니어링활동"이라 함은 과학기술의 지식을 응용하여 수행하는 사업 및 시설물에 관한 연구·기획·타당성조사·설계·분석·계약·구매·조달·시험·감리·시험운전·평가·검사·안전성검토·관리메뉴얼작성.자문·지도, 유지 또는 보수, 견적 · 설계의 경제성 및 기능성 검토 · 시스템의 분석 및 관리 활동과 그 활동에 대한 사업관리를 말한다.

1-2-3 엔지니어링사업

○ 본 표준품셈상의 엔지니어링사업이라 함은 국내·외에서 추진되고 있는 엔지니어링활동을 수행하는 사업으로서, 엔지니어링산업 진흥법의 규정에 의한 엔지니어링사업을 준용한다.

※ 엔지니어링산업 진흥법 제2조(정의)
"엔지니어링사업"이란 엔지니어링활동을 수행하는 사업을 말한다.

1-2-4 엔지니어링사업자

○ 본 표준품셈상의 엔지니어링사업자라 함은 엔지니어링활동을 영업의 수단으로 하려는 자로서, 엔지니어링산업 진흥법의 규정에 의한 엔지니어링사업자와 기술사법에 의한 기술사사무소 개설등록업체를 포함하며 각각의 관련규정을 준용한다.

※ 엔지니어링산업 진흥법 제2조(정의)
"엔지니어링사업자"란 엔지니어링활동을 영업의 수단으로 하려는 자로서 산업통상자원부장관에게 신고한 자를 말한다.

※ 기술사법 제6조 (기술사사무소의 개설등록 등)
기술사가 개업하기 위하여 사무소를 개설하려면 미래창조과학부장관에게 등록을 하여야 한다.

1-2-5 발주자

○ 본 표준품셈상의 발주자라 함은 엔지니어링사업을 발주하는 자로서, 엔지니어링산업 진흥법의 규정에 의한 발주청 외에 민간기관(단체) 및 개인 등을 포함한다.

※ 엔지니어링산업 진흥법 제2조(정의), 동법 시행령 제5조
"발주청"이란 엔지니어링사업을 발주하는 자로서, 국가, 지방자치단체, 공공기관, 사회기반시설의 사업시행자 또는 위탁받은 자, 지방공사, 지방공단, 출연기관, 위탁사업시행자, 관리시설물 사업시행자를 말한다.

제2절 품셈구성

○ 본 표준품셈의 구성은 총칙과 각 장으로 나누어 기술한다.

○ 총칙에서는 엔지니어링사업대가의 기본구성내용과 계산체계를 기술하며, 각 장에서는 자료제공의 전제와 표준업무내용에 따라 직접비와 간접비를 별도로 구성하고, 표준업무의 분류 및 표준업무 품 산정의 원단위, 단위별로 변화되는 수정·보정치를 업무분류에 따라 기술한다.

○ 본 표준품셈의 체계는 "엔지니어링사업대가의 기준"에 따라 다음과 같이 구성한다.

도시계획 및 조경 관련업무의 품셈체계

- 엔지니어링 사업대가
  - 직접비
    - 직접인건비
    - 직접경비
      - 여비
      - 특수자료비, 신기술 (특허, 노하우 등의 사용료)
      - 제출도서의 인쇄 및 청사진비
      - 측량비
      - 토질 및 재료의 시험 등의 시험비 및 조사비
      - 모형·조감도 제작비
      - 타전문기술자의 자문비 및 위탁비
      - 전산관련 성과품 제작비 (중간 또는 최종)
      - 현장조사비 (디지털사진, 비디오촬영·현상·인화·편집비 등)
      - 업무추진비 (공청회, 관련부처협의시 자문비, 회의(협의)준비비 등)
      - 현장 운영비 등
  - 간접비
    - 제경비
      - 업무관리비
      - 일반관리비
    - 기술료
      - 기술연구비
      - 기술개발비
      - 기술훈련비
      - 조사연구비
      - 이윤 및 기타 (엔지니어링사업대가의 기준 중 기술료의 산정방식에 의함)

※ 부가가치세는 부가가치세법에 따라 별도 계상한다.

제3절 품셈 산정기준

3-1 구성 비목의 내용과 품 산정

○ 본 표준품셈 업무의 엔지니어링사업대가의 구성 비목은 “엔지니어링사업대가의 기준”에 따르며, 그 품방법은 다음과 같다.

3-1-1 직접비

○ 직접비란 해당업무를 수행하기 위한 직접인건비와 직접경비의 합을 말한다.

1. 직접인건비

1) 직접인건비 산정기준

○ 직접인건비라 함은 해당업무에 직접 종사하는 엔지니어링기술자의 급료, 제수당, 상여금, 퇴직적립금, 산재보험금 등을 포함한 금액을 말한다.

○ 직접인건비는 각 업무별로 직접 종사하는 엔지니어링기술자의 소요인력을 각 장별로 정한 표준업무의 분류 및 표준업무 품 산정의 원단위에 보정계수를 곱하여 산정하고, 산정된 엔지니어링기술자의 등급별 소요인력과 노임단가를 곱하여 산정한다.

○ 엔지니어링기술자 등급별 노임단가 적용기준

- 직접인건비 품 산정을 위한 엔지니어링기술자의 등급별 엔지니어링사업 노임단가는 “엔지니어링사업대가의 기준”에 따라 조사·공표된 금액을 적용한다.

○ 작업량관련 소요작업량의 계상시(수정과 보정 포함)에 소수점 넷째 자리에서 반올림하여 소수점 셋째 자리 단위까지 적용 산정한다. (예: 0.123)

2) 직접인건비 직종구분

○ 엔지니어링기술자의 등급구분 및 자격기준

- 엔지니어링기술자의 등급구분 및 자격기준은 “엔지니어링산업 진흥법 및 시행령”의 분류에 따른다.

엔지니어링기술자의 등급구분 및 자격기준

(엔지니어링산업 진흥법 시행령 별표2 : 2013.1.1.이후)

구분 \ 기준		국가기술자격자	학력자
기술계 엔지니어링 기술자	기술사	기술사	-
	특급기술자	기사 10년 이상 산업기사 13년 이상	-
	고급기술자	기사 7년 이상, 산업기사 10년 이상	-
	중급기술자	기사 4년 이상, 산업기사 7년 이상	-
	초급기술자	기사, 산업기사 2년 이상	석사, 학사, 전문대졸 3년이상
숙련계 엔지니어링 기술자	고급숙련기술자	기능장, 산업기사 4년 이상, 기능사 7년 이상, 기능사보 10년 이상	-
	중급숙련기술자	산업기사, 기능사 3년 이상, 기능사보 5년 이상	-
	초급숙련기술자	기능사 기능사보 2년 이상	고졸 1년 이상

주 : ①기술자라 함은 엔지니어링산업 진흥법 제2조(정의) 제1호 및 동법 시행령 제2조(정의)에서 규정한 엔지니어링 활동을 직접 수행하는 자로서, 제경비에 포함되어 있는 임원·서무·경리직원 등을 제외한 자를 말한다.

②그 밖의 사항은 엔지니어링산업 진흥법 시행령 [별표 2]와 관계 법령에 따른다.

○ 기술자의 등급별 작업내용

- 기술자의 등급별 주요작업내용은 다음의 표와 같다.

기술자 등급별 작업내용

구 분	작업내용
기술사	해당 기술분야에 대한 고도의 전문지식과 실무경험에 입각한 계획, 연구, 설계, 분석, 시험, 운영, 시공, 평가 또는 이에 관한 지도·감리 등의 기술업무의 수행과 업무의 총괄
특급기술자	해당 기술분야에 관한 공학적 전문지식과 실무경험에 입각한 계획, 연구, 설계, 분석, 시험, 운영, 시공, 평가 또는 이에 관한 지도·감리 등의 기술업무의 수행
고급기술자	해당 기술분야에 관한 공학적 전문지식과 그 응용능력을 갖고 상기업무에 관한 엔지니어링활동의 직접수행 및 하급기술자의 지휘, 감리 등의 기술업무의 수행
중급기술자	해당 기술분야에 관한 기술 기초지식과 그 응용능력을 갖고 상기 업무에 관한 엔지니어링활동의 직접 수행
초급기술자	해당 기술분야에 관한 초급단계의 기초지식과 그 적용능력을 갖고 상기 업무에 관한 실제적 초급기술업무의 수행
보조원	해당 기술분야에 관한 초보적 단계의 기초적인 기술업무 수행능력을 갖고 있는 기술자로서 기술 보조업무의 수행

주 : 보조원 인건비는 작업공정의 평균치를 감안하여 중급숙련기술자로 갈음한다

2. 직접경비

○ 직접경비란 당해 업무수행에 직접 필요한 여비, 특수자료비, 신기술(특허, 노하우 등의 사용료), 제출도서의 인쇄 및 청사진비, 측량비, 토질 및 재료의 시험 등의 시험비 및 조사비, 모형·조감도제작비, 타 전문기술자의 자문비 또는 위탁비와 현장운영비(직접인건비에 포함되지 아니한 보조요원의 급여와 현장사무실의 운영비 등), 전산관련 성과품 제작비(중간 또는 최종), 현장조사비(디지털사진, 비디오촬영·현상·인화·편집비 등), 업무추진비(공청회, 관련부처 협의시 자문비, 회의(협의)준비비 등), 현장 운영비, 설문조사비, 현장방문조사비 등을 포함한 것으로써 그 실비를 계산한다.

○ 직접경비의 계산은 총칙 후단 "업무별 직접경비 적용방안 (예시)" 를 참고하여 필요한 항목을 선택적으로 적용한다.

3-1-2 간접비

○ 간접비란 기술업무 수행시 관련되는 경비로써, 제경비, 기술료로 구성되는 비용을 말한다.

간접비 ─┬─ 제경비
　　└─ 기술료

1. 제경비

○ 제경비란 직접비(직접인건비 및 직접경비)에 포함되지 아니하는 비용으로서 업무관리비, 일반관리비 등의 간접비를 말하며, 임원, 서무, 경리직원 등의 급여, 사무실비, 광열수도비, 사무용 소모품비, 비품비, 기계기구의 수선 및 감가상각비, 통신운반비, 업무추진 관련 자체회의비, 공과금, 영업활동비용 등을 포함하는 것으로서 계산은 3-1-3의 업무별 엔지니어링사업대가 적용방법에 의한다.

2. 기술료

○ 기술료라 함은 엔지니어링사업자가 개발·보유한 기술의 사용 및 기술축적을 위한 대가로서 기술연구비, 기술개발비, 기술훈련비, 조사연구비 및 이윤 등을 포함한 것으로서 계산은 3-1-3 업무별 엔지니어링사업대가 적용방법에 의한다.

3-1-3 업무별 엔지니어링사업대가 적용방법

○ 직접인건비를 "A"라하면 업무별 엔지니어링사업대가 적용은 다음의 표에 의한다.

업무구분		제경비(원)	기술료(원)
제2장 국토 및 지역계획	1절.국토종합계획	-	-
	2절.부문별계획	-	-
	3절.도 종합계획	-	-
	4절.지역계획	A × 120%	(A+제경비) × 25%
	5절.농·산·어촌계획	A × 120%	(A+제경비) × 25%
제3장 도시계획	1절.광역도시계획	A × 120%	(A+제경비) × 25%
	2절.도시·군기본계획	A × 120%	(A+제경비) × 25%
	3절.도시·군관리계획		
	1.도시·군관리계획(재정비)	A × 120%	(A+제경비) × 25%
	2.도시·군관리계획(변경)결정 (부분·단위)	A × 120%	(A+제경비) × 25%
	4절.도시(지역)교통계획	A × 120%	(A+제경비) × 25%
	5절.지형도면고시계획	A × 110%	(A+제경비) × 20%
	6절.단계별집행계획		
	1.단계별집행계획	A × 110%	(A+제경비) × 25%
	2.단위계획시설 집행계획	A × 110%	(A+제경비) × 25%
	7절.개발제한구역 관리계획	A × 120%	(A+제경비) × 30%
	8절.도시계획 기초조사		
	1.도시·군관리계획을 위한 기초조사	A × 120%	(A+제경비) × 20%
	2.기타계획을 위한 기초조사	A × 120%	(A+제경비) × 20%
	9절.성장관리방안		
	1.성장관리지역 설정	A × 120%	(A+제경비) × 25%
	2.성장관리방안 수립	A × 120%	(A+제경비) × 25%
	10절.개발행위허가	A × 120%	(A+제경비) × 25%
	11절.도시방재계획	A × 120%	(A+제경비) × 20%
	12절.저탄소 녹색도시계획	A × 120%	(A+제경비) × 30%
제4장 도시설계	1절.지구단위계획		
	1. 구역지정	A × 120%	(A+제경비) × 30%
	2. 지구단위계획	A × 120%	(A+제경비) × 30%
	2절.마을만들기	A × 120%	(A+제경비) × 30%
제5장 도시개발	1절.도시개발구역지정	A × 120%	(A+제경비) × 30%
	2절.환지방식 개발계획	A × 120%	(A+제경비) × 30%
	3절.주택단지 개발계획	A × 120%	(A+제경비) × 30%
	4절.산업단지 개발계획	A × 120%	(A+제경비) × 30%
	5절.캠퍼스계획	A × 120%	(A+제경비) × 30%
	6절.유통(물류)단지 개발계획	A × 120%	(A+제경비) × 30%

업무구분		제경비(원)	기술료(원)
제6장 도시재생	1절.도시재생계획		
	1.도시재생전략계획	A × 120%	(A+제경비) × 30%
	2.도시재생활성화계획	A × 120%	(A+제경비) × 30%
	2절.재정비촉진계획		
	1.재정비촉진지구 지정	A × 120%	(A+제경비) × 30%
	2.재정비촉진계획	A × 120%	(A+제경비) × 30%
	3절.도시 및 주거환경정비계획		
	1.도시 및 주거환경정비기본계획	A × 120%	(A+제경비) × 30%
	2.도시 및 주거환경정비계획		
	2.1.구역지정(정비계획)	A × 120%	(A+제경비) × 30%
	2.2.주거환경개선사업	A × 120%	(A+제경비) × 30%
	2.3.주거환경관리사업	A × 120%	(A+제경비) × 30%
	2.4.구역해제 및 관리방안	A × 120%	(A+제경비) × 30%
	3.가로주택정비사업(사업계획)	A × 120%	(A+제경비) × 20%
	4.사업시행계획	A × 120%	(A+제경비) × 30%
	5.관리처분계획	A × 120%	(A+제경비) × 30%
	4절.리모델링 기본계획	A × 120%	(A+제경비) × 30%
제7장 도시경관	1절.도시경관계획		
	1.시·군 경관계획	A × 120%	(A+제경비) × 30%
	2.도시·군경관부문계획	A × 120%	(A+제경비) × 30%
	2절.지구경관계획		
	1.개발사업 경관계획 (사전경관계획 비수립)	A × 120%	(A+제경비) × 30%
	2.개발사업 경관계획 (사전경관계획 수립)	A × 120%	(A+제경비) × 30%
	3.경관상세계획	A × 120%	(A+제경비) × 30%
	4.농산어촌경관계획	A × 120%	(A+제경비) × 30%
	5.경관기본설계	A × 120%	(A+제경비) × 30%
	3절.사회기반시설사업 등의 경관심의		
	1.사회기반시설사업 경관심의	A × 120%	(A+제경비) × 30%
	2.건축물 경관심의	A × 120%	(A+제경비) × 30%
제8장 도시평가	1절.국토계획평가	A × 110%	(A+제경비) × 30%
	2절.토지적성평가	A × 110%	(A+제경비) × 25%
	3절.재해취약성분석	A × 110%	(A+제경비) × 25%
	4절.환경성검토	A × 110%	(A+제경비) × 30%

업무구분		제경비(원)	기술료(원)
제8장 도시평가 (계속)	5절.교통성검토	A × 110%	(A+제경비) × 30%
	6절.경관성검토	A × 110%	(A+제경비) × 30%
	7절.사전재해영향성검토		
	1.행정계획(시·군·구 단위이상계획)	A × 115%	(A+제경비) × 30%
	2.행정계획(일반사업계획)	A × 115%	(A+제경비) × 30%
	3.개발사업	A × 115%	(A+제경비) × 30%
	8절.교육환경평가	A × 120%	(A+제경비) × 30%
	9절.도시계획지속가능성평가	A × 110%	(A+제경비) × 30%
	10절.환경평가검증에 관한 업무	A × 110%	(A+제경비) × 20%
제9장 공원·관광지.유원지.체육시설 등의 계획	1절.공원녹지 기본계획	A × 120%	(A+제경비) × 30%
	2절.도시녹화계획	A × 120%	(A+제경비) × 30%
	3절.공원계획		
	1.자연공원	A × 120%	(A+제경비) × 30%
	2.도시공원	A × 120%	(A+제경비) × 30%
	4절.관광지·유원지·휴양지·체육시설지 계획	A × 120%	(A+제경비) × 30%
	5절.문화재 사적지 계획	A × 120%	(A+제경비) × 30%
제10장 조경특화계획	1절.도로조경계획	A × 120%	(A+제경비) × 30%
	2절.시가지광장과 건축관련 공간계획	A × 120%	(A+제경비) × 30%
	3절.단지조경계획		
	1.주택단지조경	A × 120%	(A+제경비) × 30%
	2.산업단지단지조경	A × 120%	(A+제경비) × 30%
	4절.환경 생태복원계획	A × 120%	(A+제경비) × 30%
	5절.개발제한구역 조경설계검토 도서 작성	A × 120%	(A+제경비) × 30%
제11장 사업관리	1절.사업타당성 조사분석 업무		
	1.도시개발부문-시가지개발사업	A × 110%	(A+제경비) × 25%
	2.도시개발부문-도시시설개발	A × 110%	(A+제경비) × 25%
	3.도시개발부문-지역개발부문	A × 110%	(A+제경비) × 25%
	2절.농지전용	A × 110%	(A+제경비) × 20%
	3절.산지전용	A × 110%	(A+제경비) × 20%
	4절.총괄계획관리	-	-
	5절.계획관리	-	-
	6절.사후관리계획	A × 120%	(A+제경비) × 30%
	7절.도시계획 퍼실리테이션	A × 120%	(A+제경비) × 30%

※ 직접경비와 부가가치세는 별도 계상한다.

3-2 기술업무 대상과 범위

○ 기술업무 대상과 범위는 각 장별로 업무항목에 해당하는 내용이 다르므로 각 장의 업무범위와 추진과정에서 기술한다.

3-3 기타 적용

○ 부가가치세법에 의한 부가가치세의 산정은 부가가치세법에 따라 별도 계상한다.

○ 제2장에서 제11장까지 “사례”가 없는 것은 총칙에 의하고, 총칙에 없는 것은 일반적 관례에 의한다.

○ 과업의 특수성에 따른 별도의 적용은 특수여건을 감안하여 엔지니어링사업자와 발주자간의 협의에 의하여 정한다.

제4절 품셈 운영기준

4-1 기본 운영기준

4-1-1 과업내용서와 내역서의 일치

○ 과업내용서(과업지시서) 및 내역서는 국토계획 표준품셈을 준수하여 작성한다.

○ 과업내용서와 내역서가 불일치할 경우에는 내역서를 기준으로 적용한다.

4-1-2 저가 낙찰 및 계약방지를 위한 표준품셈 금액대비 발주금액 비율 준수

○ 표준품셈 금액 대비 발주금액은 최소 90%이상이 되도록 한다.

4-1-3 국토계획업무가 타 분야 발주업무에 포함되어 발주되는 경우에는 본 품셈을 적용하여 발주토록 준수

○ 국토계획업무가 타 분야 발주업무에 포함되어 발주되는 경우에도 본 국토계획 표준품셈의 적용대상은 본 품셈을 적용하여야 한다.

4-1-4 국토계획업무가 발주자 자체의 내부품으로 발주되는 경우에는 본 품셈을 기준으로 작성하여 발주토록 준수

○ 국토계획업무 발주를 위해 발주자 자체 내부발주기준을 수립할 경우 해당 품셈은 본 품셈을 기준으로 작성되어야 한다.

4-1-5 기술제안서 평가시 설계보상제 시행 준수

○ 발주자는 발주방법으로 현상공모서 작성, 기술제안서 평가 등을 시행할 경우 비용보상을 시행하는 것을 원칙으로 한다.

○ 현상공모, 기술제안서 등 작성에 소요되는 비용은 설계보상비예산 및 지급관련 기준에 의거 보상하여야 한다.

4-1-6 통합발주를 위한 품셈적용 지침

○ 사업의 효율적 집행 및 절차 간소화를 위하여 복수의 엔지니어링사업을 통합발주 할 경우 과업의 성격에 따라 중복과업 내역을 조정하여야 한다.

○ 단계별 내역이 상호 중복되어 그 중 하나를 삭제할 경우, 원활한 과업수행과 부실방지를 위하여 그 중 높은 품셈을 기준으로 적용한다.

4-1-7 신규 엔지니어링사업 업무 발생에 따른 품셈기준 작성 및 활용

○ 여건변화에 따라 표준품셈에서 정립되지 않은 신규업무 발생 시 기존 품셈기준 중 가장 유사한 품셈기준을 적용하거나, 둘이상의 다른 품셈기준을 조합하여 적용할 수 있다.

4-2 세부 운영기준

4-2-1 총칙 제3절 품셈 산정기준에 의거 직접비 적용 준수

○ 직접인건비는 표준단위 업무분류와 원단위에서 제시된 기술업무의 직능별 직접인력 소요량을 준수한다.

○ 일부변경으로 발주되는 표준업무는 표준단위 업무분류와 원단위에서 제시된 기술업무의 직능별 직접인건비 소요 총량의 50 ~ 100%가 적용되도록 한다.

○ 직접경비는 품셈에서 제시된 항목의 실비를 계산하여 집행하며 추가비용 발생 시에는 준공 시에 정산하여 집행되도록 한다.

※ 일부변경이란 계획안이 작성되고 주민공람, 의회보고, 공청회, 정책심의회 등을 거친 경우, 과업이 사실상 마무리된 이후 발주자 사정에 의한 변경이 필요한 경우를 의미한다.

4-2-2 총칙 제3절 품셈 산정기준에 의거 표준업무의 간접비 요율 준수

○ 제1장 총칙 3-1-3 업무별 엔지니어링사업대가 적용방법에서 제시된 제경비, 기술료 요율을 준수한다.

4-2-3 간접조사방식 외 기초자료 수집에 따른 추가비용 산정 및 정산 준수

○ 업무별 자료제공의 전제를 준수하여 간접조사방식 외 기초자료 수집에 따른 추가비용이 발생할 경우 이에 대한 정당한 대가를 별도 산정 및 정산토록 한다.

4-2-4 주민참여 확대에 따른 품셈 적용기준 준수

○ 업무별 다양한 주민참여에 대한 품셈 적용기준을 준수하여야 한다.

4-2-5 보고, 협의, 심의, 자문 등 과다한 기술협의 이행의 품셈적용기준 준수

○ 보고, 협의, 심의, 자문 등 과다한 기술협의 이행의 품셈적용기준을 준수하되 초과 비용에 대해서는 추가비용을 산정 및 정산토록 한다.

○ 특히 최근 강화되고 있는 주민참여 확대에 적극적으로 대응할 수 있도록 비용 현실화를 위해 상호 협조하여야 한다.

4-2-6 계획안 및 과업기간 변경에 따른 품셈 산정기준 준수

○ 계획안이 작성되고 확정된 후 발주자 등의 사정에 의하여 계획안의 변경·재작업이 수행되는 경우에는 그 변경·재작업의 정도에 따라 비용을 추가 지급하여야 한다.

○ 과업수행 중 정부 회계연도의 경과나 발주자의 사정에 따라 인·허가나 보고, 협의, 심의 등 행정절차의 이행이 장기간 지연되거나, 과업중지시 보고, 협의, 검토, 보완 지시 등으로 인하여 추가적인 과업수행 비용이 발생할 경우에는 그 정도에 따라 비용을 추가 지급하여야 한다.

4-3 기타 준수사항

○ 상기 4-1, 4-2에서 언급한 사항 외에도 내역서에 반영되지 않은 업무나 발주자 요구에 의하여 업무별 추가비용이 발생할 경우 표준품셈 기조를 존중하여 정산하여야 한다.

업무별 직접경비 적용방안 (예시)

업무구분		여비	특허, Know-How 등의 사용료		제출도서 인쇄 및 청사진비	측량비	토질및재료의 시험 등		제작비		타전문 기술자		전산관련 성과품 제작비	현장조사비		업무추진비			현장 운영비
			특수 자료비	신기술			시험비	조사비	모형도	조감도	자문비	위탁비		디지털 사진 현상·인화	비디오촬영편집비 등	공청회	관련부처협의시 자문비	회의(협의)준비비등	
국토 및 지역 계획	·국토종합계획	○			○						○		○			○	○	○	
	·부문별계획	○			○						○		○			○	○	○	
	·도 종합계획	○			○						○		○			○	○	○	
	·지역계획	○			○						○		○	○		○	○	○	
	·농·산·어촌계획	○			○						○		○	○		○	○	○	
도시 계획	·광역도시계획	○			○						○	○	○	○		○	○	○	○
	·도시·군기본계획	○			○						○	○	○	○		○	○	○	○
	·도시·군관리계획(재정비)	○			○	○					○	○	○	○		○	○	○	○
	·도시·군관리계획(변경)결정 (단위)	○			○	○				○	○	○	○	○		○	○	○	
	·도시(지역)교통계획	○	○	○	○						○	○	○	○		○	○	○	
	·지형도면고시계획	○			○	○							○	○		○		○	
	·단계별집행계획	○			○						○		○	○			○	○	
	·단위계획시설 집행계획	○			○								○	○			○	○	
	·개발제한구역 관리계획	○			○						○		○	○		○	○	○	
	·기초조사/도시·군관리계획	○			○	○					○		○	○			○	○	
	·기초조사/기타계획	○			○	○					○		○	○			○	○	
	·성장관리지역 설정	○			○						○	○	○	○			○	○	
	·성장관리방안 수립	○			○						○	○	○	○		○	○	○	
	·개발행위허가	○			○	○					○		○	○			○	○	
	·도시방재계획	○			○						○	○	○	○			○	○	
	·저탄소 녹색도시계획	○			○						○	○	○	○			○	○	
도시 설계	·지구단위계획/구역지정	○			○	○			○	○	○		○	○		○	○	○	
	·지구단위계획/지구단위계획	○			○	○			○	○	○		○	○		○	○	○	
	·마을만들기	○			○	○				○	○		○	○		○	○	○	
도시 개발	·도시개발구역 지정	○			○	○	○	○	○	○	○		○	○		○	○	○	○
	·환지방식 개발계획	○			○	○	○	○	○	○	○		○	○		○	○	○	○
	·주택단지 개발계획	○			○	○	○	○	○	○	○		○	○		○	○	○	○
	·산업단지 개발계획	○			○	○	○	○	○	○	○		○	○		○	○	○	○
	·「캠퍼스」계획	○			○	○	○	○	○	○	○	○	○	○		○	○	○	○
	·유통(물류)단지 개발계획	○			○	○	○	○	○	○	○		○	○		○	○	○	
도시 재생	·도시재생전략계획	○			○	○				○	○		○	○		○	○	○	
	·도시재생활성화계획	○			○	○			○	○	○		○	○		○	○	○	
	·재정비촉진지구 지정	○			○	○				○	○		○	○		○	○	○	
	·재정비촉진계획	○			○	○			○	○	○		○	○		○	○	○	
	·도시 및 주거환경정비기본계획	○			○	○				○	○		○	○		○	○	○	
	·구역지정(정비계획)	○			○	○				○	○		○	○		○	○	○	
	·주거환경개선사업	○			○	○			○	○	○		○	○		○	○	○	

업무구분		여비	특허, Know-How 등의 사용료		제출도서 인쇄 및 청사진비	측량비	토질및재료의 시험 등		제작비		타전문 기술자		전산관련 성과품 제작비	현장조사비		업무추진비			현장 운영비
			특수자료비	신기술			시험비	조사비	모형도	조감도	자문비	위탁비		디지털 사진 현상·인화	비디오촬영편집비 등	공청회	관련부처협의시 자문비	회의(협의) 준비비등	
도시재생	·주거환경관리사업	○			○	○			○	○	○		○	○		○	○	○	
	·가로주택정비사업(사업계획)	○			○	○			○	○	○		○	○		○	○	○	
	·사업시행계획	○			○	○							○			○	○	○	
	·관리처분계획	○			○	○							○			○	○	○	
도시경관	·시·군 경관계획	○		○	○	○			○	○	○		○	○	○	○	○	○	
	·도시·군 경관부문계획	○		○	○	○			○	○	○		○	○		○	○	○	
	·개발사업 경관계획(사전경관계획 비수립)	○		○	○	○			○	○	○		○	○	○	○	○	○	
	·개발사업 경관계획(사전경관계획 수립)	○		○	○	○			○	○	○		○	○	○	○	○	○	
	·경관상세계획	○		○	○	○			○	○	○		○	○	○	○	○	○	
	·농·산·어촌 경관계획	○		○	○	○				○	○		○	○		○	○	○	
	·경관기본설계	○		○	○				○	○	○		○	○	○	○	○	○	
	·사회기반시설사업 경관심의	○		○	○				○	○	○		○	○		○	○	○	
	·건축물 경관심의	○		○	○				○	○	○		○	○		○	○	○	
도시평가	·국토계획평가	○			○						○		○						
	·토지적성평가	○			○								○	○					
	·재해취약성 분석	○			○						○		○	○					
	·환경성검토	○			○						○		○	○					
	·교통성검토	○			○						○		○	○	○				
	·경관성검토	○			○					○	○		○	○					
	·사전재해영향성검토 : 행정계획	○			○						○		○	○			○	○	
	·사전재해영향성검토 : 일반사업계획	○			○						○		○	○			○	○	
	·사전재해영향성검토 : 개발사업	○			○						○		○	○			○	○	
	·교육환경평가	○			○						○		○	○					
	·도시계획지속가능성평가	○			○						○		○	○					
	·환경평가검증에 관한 업무	○			○						○		○						
공원관광지유원지체육시설등의계획	·공원녹지 기본계획	○			○	○				○	○		○	○	○	○	○	○	
	·도시녹화계획	○			○	○				○	○		○	○	○	○	○	○	
	·공원계획	○			○	○	○	○	○	○	○		○	○		○	○	○	
	·관광지·유원지·휴양지·체육시설지 계획	○			○	○	○	○	○	○	○		○	○		○	○	○	
	·문화재 사적지 계획	○		○	○	○	○	○	○	○	○	○	○	○	○	○	○	○	
조경특화계획	·도로조경계획	○		○	○	○	○	○		○	○		○	○			○	○	
	·시가지광장과 건축관련 공간계획	○		○	○	○	○	○	○	○	○		○	○	○	○	○	○	
	·단지조경계획	○		○	○	○				○	○		○	○			○	○	
	·환경·생태복원계획	○		○	○	○	○	○	○	○	○	○	○	○	○	○	○	○	
	·개발제한구역 조경설계검토 도서작성	○			○	○							○	○			○	○	

업무구분		여비	특허, Know-How 등의 사용료		제출도서 인쇄 및 청사진비	측량비	토질및재료의 시험 등		제작비		타전문 기술자		전산관련 성과품 제작비	현장조사비		업무추진비			현장 운영비
			특수자료비	신기술			시험비	조사비	모형도	조감도	자문비	위탁비		디지털 사진 현상·인화	비디오촬영편집비 등	공청회	관련부처협의시 자문비	회의(협의) 준비비등	
사업관리	·사업타당성 분석 : 시가지개발사업	○			○						○		○						
	·사업타당성 분석 : 도시시설개발	○			○						○		○						
	·사업타당성 분석 : 지역개발부문	○			○						○		○						
	·농지전용	○			○								○						
	·산지전용	○			○								○				○		
	·총괄계획관리(PPM)	○			○								○				○		
	·계획관리	○			○						○		○				○		
	·사후관리계획	○			○						○		○				○		
	·도시계획 퍼실리테이션	○			○								○						

※ 상기의 직접경비 항목의 ○의 표기사항은 발주시에 통상적으로 사용되는 직접경비이며, 발주청에서 과업발주시 참고하여 작성하시기 바라며, 발주자의 요청에 의하여 ○로 표기된 사항 이외에 추가하거나 항목을 조정하여 사용할 수 있습니다.

제2장 국토 및 지역계획

제1절 국토종합계획

제2절 부문별계획

제3절 도 종합계획

제4절 지역계획

제5절 농·산·어촌계획

제1절 국토종합계획

1-1 정 의

○ 국토종합계획은 국토를 이용·개발·보전함에 있어서 미래의 경제적·사회적 변동에 대응하여 국토가 지향하여야 할 장기방향을 제시하는 종합계획이고, 20년 단위로 수립하는 장기계획이다. 향후 수립될 각종 공간계획의 기본이 되며, 각 부문별계획과 지역계획 등은 국토종합계획에서 제시하는 방향과 조화를 이루어야 한다.

국토계획의 체계

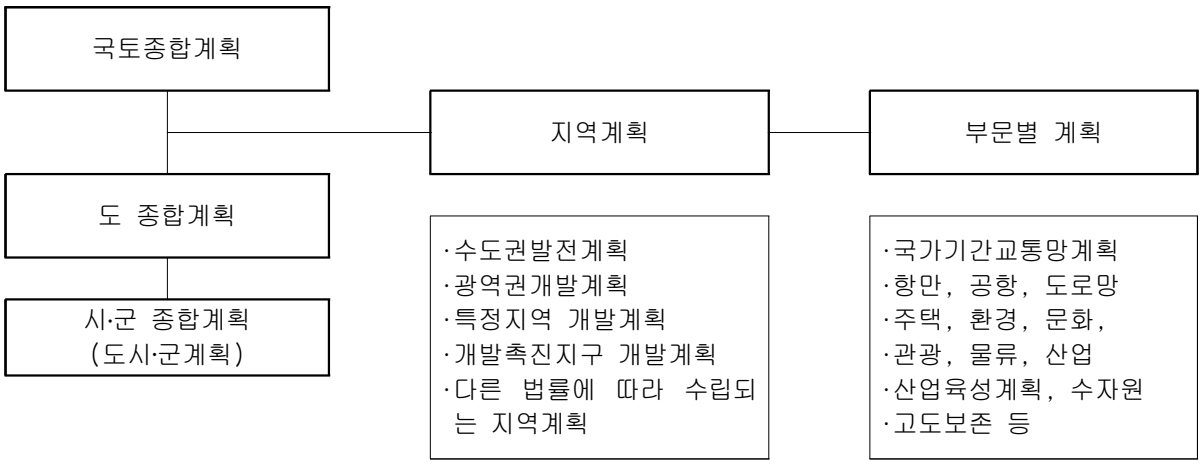

1-2 자료제공의 전제

○ 당해 계획의 수립에 필요한 모든 관련자료는 원칙적으로 발주자가 제공하는 것으로 하되, 보유하지 않는 자료는 엔지니어링사업자가 수집한다.

○ 발주자가 제공하지 못하는 자료의 조사에 있어서는 그 규모·내용에 의거하여 별도의 엔지니어링사업대가를 산정하여 엔지니어링사업자가 수행하며, 당해 관련자료의 기밀성과 광범위한 자료가 요구되므로 조사·분석에 필요한 상당기간과 자료수집비용이 전제되어야 한다.

1-3 업무범위와 추진과정

1-3-1 업무범위

○ 국토전역을 대상으로 하여 미래의 경제적·사회적 변동에 대응하여 민족 삶의 터전인 국토의 미래상과 장기적 발전방향을 종합적으로 설정함으로써 인구와 산업의 배치, 기반시설의 공급, 주민생활환경의 개선, 국토자원의 관리 및 환경보전에 관한 정책방향을 제시하는 국가의 최상위 국토종합계획을 작성한다.

1-3-2 추진과정

○ 타부처(관계기관)와의 협의나 전문가 자문 등에 소요되는 기간은 과업수행기간에서 제외하여 그 소요기간 만큼 과업수행기간을 연장하여야 한다.

1. 계획수립추진과정

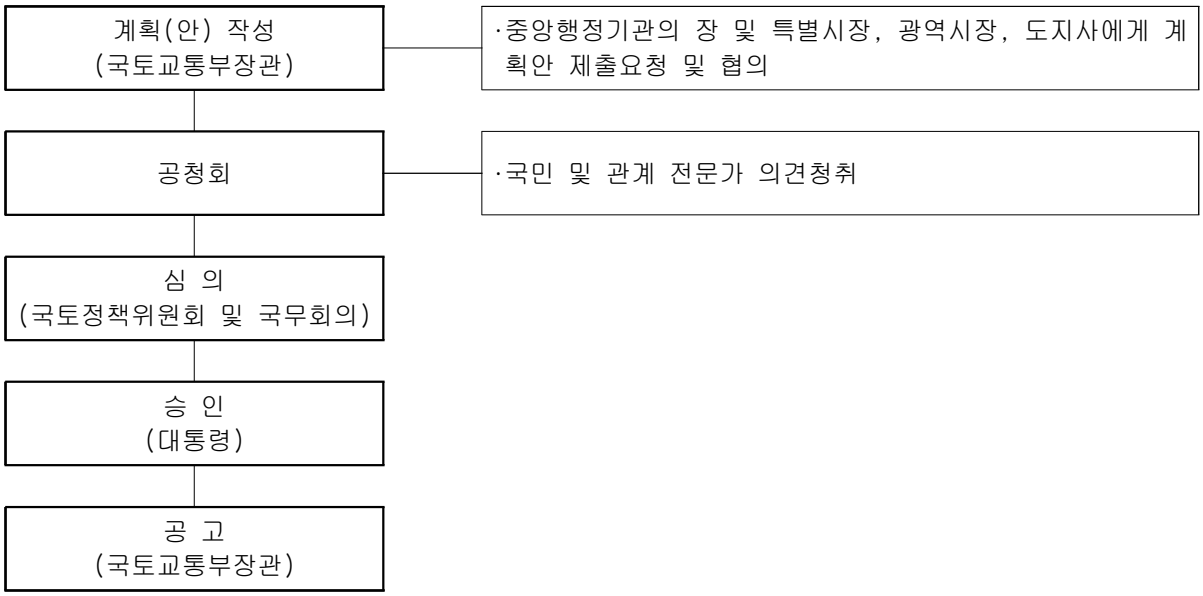

2. 과업수행추진과정

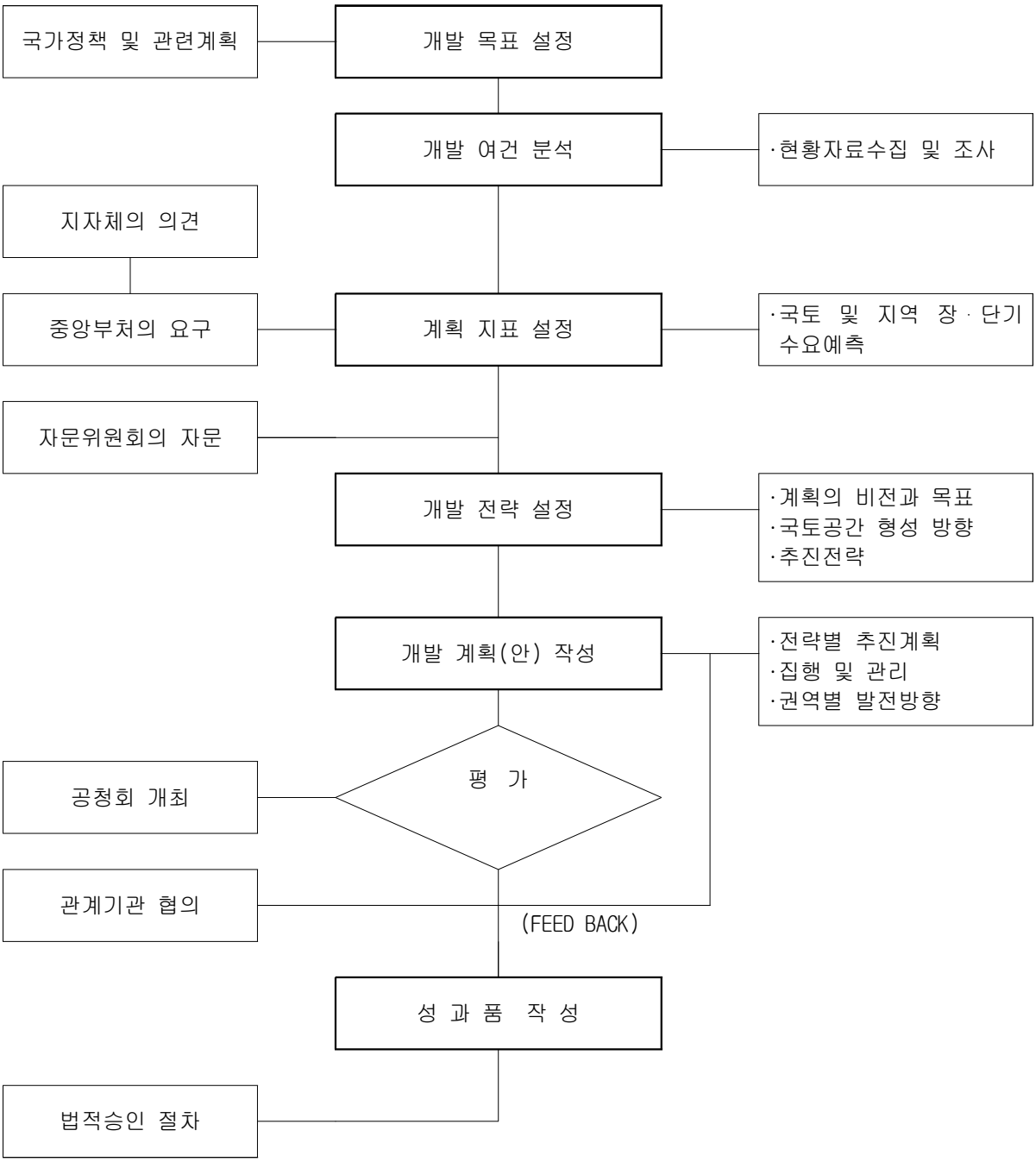

1-4 품 산정의 기준

○ 국토종합계획의 품 산정은 업무성격상 장기간의 계획수립기간과 계획의 특수성으로 다른 계획분야와 유사하게 산정하기가 난이(難易)하므로, 업무범위, 추진과정 등만을 수록하여 업무추진에 참고가 되도록 하였으며, 직접인건비 등에 관한 품 산정은 과업의 특수성을 충분히 감안하여 발주자와 엔지니어링사업자가 협의 결정하되 관련 유사부분을 준용 산정토록 한다.

제2절 부문별계획

2-1 정 의

○ 국토전역을 대상으로 하여 국토종합계획의 내용을 반영하여, 특정부문에 대한 장기적인 발전방향을 제시하는 계획이다.

2-2 자료제공의 전제

○ 당해 계획의 수립에 필요한 모든 관련자료는 원칙적으로 발주자가 제공하는 것으로 하되, 보유하지 않는 자료는 엔지니어링사업자가 수집한다.

○ 발주자가 제공하지 못하는 자료의 조사에 있어서는 그 규모·내용에 의거하여 별도의 엔지니어링사업대가를 산정하여 엔지니어링사업자가 수행하며, 당해 관련자료의 기밀성과 광범위한 자료가 요구되므로 조사·분석에 필요한 상당기간과 자료수집비용이 전제되어야 한다.

2-3 업무범위와 추진과정

2-3-1. 업무범위

○ 국토전역을 대상으로 소관업무에 관하여 국토종합계획의 내용을 반영하여 장기적인 발전방향을 제시하는 계획이다.

2-3-2. 추진과정

○ 타부처(관계기관)와의 협의나 전문가 자문 등에 소요되는 기간은 과업수행기간에서 제외하여 그 소요기간 만큼 과업수행기간을 연장하여야 한다.

1. 계획수립추진과정

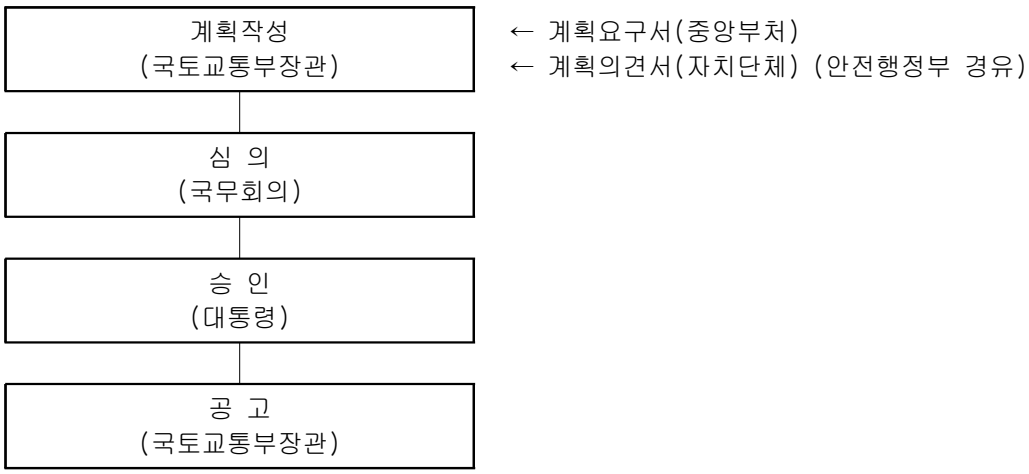

2. 과업수행추진과정

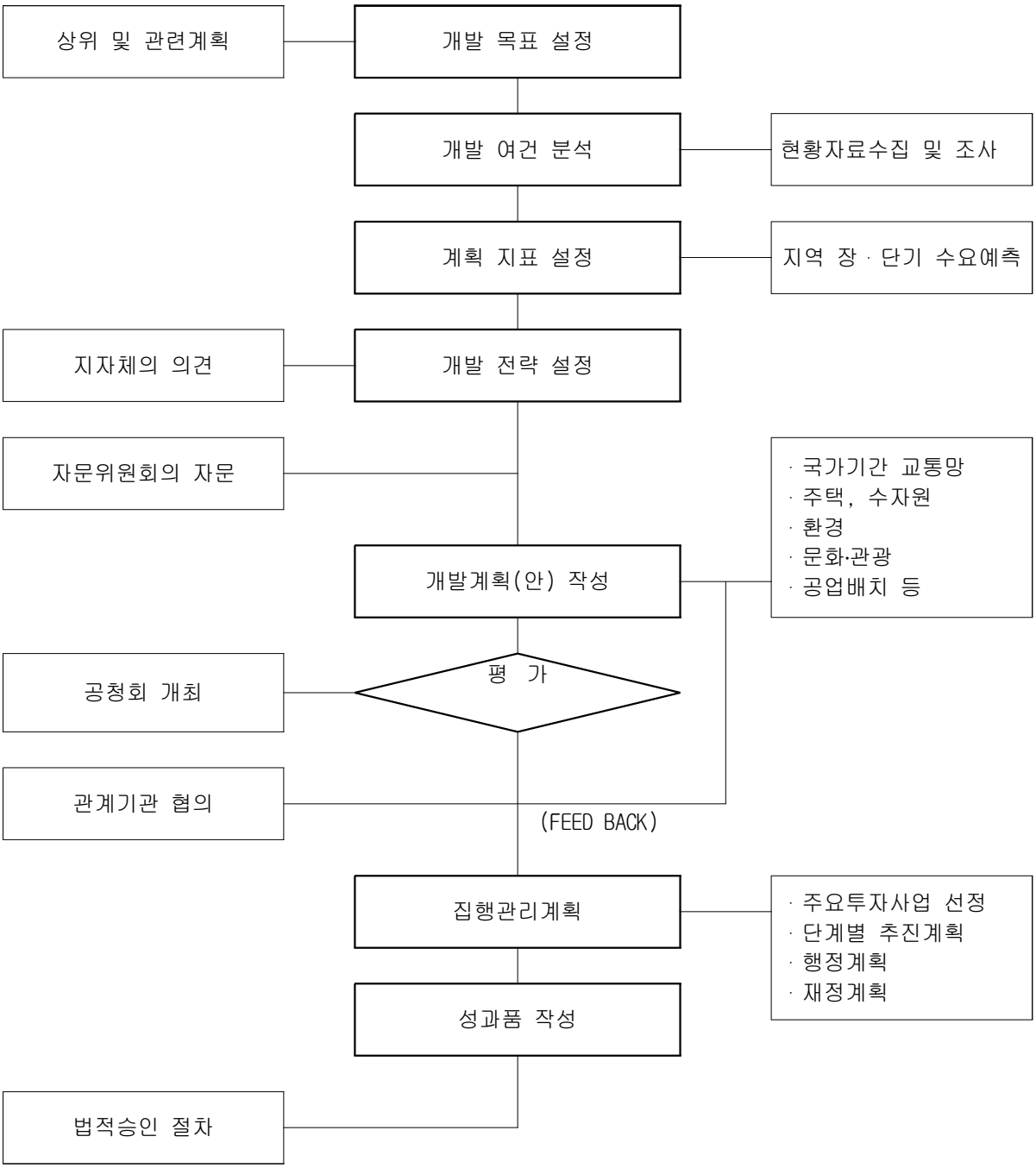

2-4 품 산정의 기준

○ 부문별계획의 품 산정은 업무성격상 장기간의 계획수립기간과 계획의 특수성으로 다른 계획분야와 유사하게 산정하기가 난이(難易)하므로, 업무범위, 추진과정 등만을 수록하여 업무추진에 참고가 되도록 하였으며, 직접인건비 등에 관한 품 산정은 과업의 특수성을 충분히 감안하여 발주자와 엔지니어링사업자가 협의 결정하되 관련 유사부분을 준용 산정토록 한다.

제3절 도 종합계획

3-1 정 의

○ 도 종합계획은 도(道) 또는 특별자치도의 관할구역을 대상으로 작성하며 지역주민의 복리향상과 지역발전에 관한 장단기 정책방향과 지침을 제시하는 종합계획이다.

3-2 자료제공의 전제

○ 당해 계획의 수립에 필요한 모든 관련자료는 원칙적으로 발주자가 제공하는 것으로 하되, 보유하지 않는 자료는 엔지니어링사업자가 수집한다.

○ 발주자가 제공하지 못하는 자료의 조사에 있어서는 그 규모·내용에 의거하여 별도의 엔지니어링사업대가를 산정하여 엔지니어링사업자가 수행하며, 당해 관련자료의 기밀성과 광범위한 자료가 요구되므로 조사·분석에 필요한 상당기간과 자료수집비용이 전제되어야 한다.

3-3 업무범위와 추진과정

3-3-1 업무범위

○ 도 종합계획은 국토종합계획 등 상위계획과 조화를 이루며, 시·군종합계획의 지침의 성격을 가지고, 방향성을 제시하여야 한다.

○ 도내 시·군의 발전방향에 관한 의견을 종합적으로 고려하여 도의 장기적인 발전방향을 수립하며, 시·군간 광역적인 조정이 필요한 사안에 대해 대안을 마련한다.

○ 도시·군기본계획 및 타 법령에 의한 시·군내 주요계획 등 관련계획의 집행성을 충분히 고려하여야 한다.

○ 바람직한 미래상을 제시하고 구체적인 실현가능한 계획을 수립하며, 계획의 실현가능성을 제고하기 위해 추진전략, 재원확보방안, 투자계획 등을 구체적으로 작성한다.

3-3-2 추진과정

○ 타부처(관계기관)와의 협의나 전문가 자문 등에 소요되는 기간은 과업수행기간에서 제외하여 그 소요기간 만큼 과업수행기간을 연장하여야 한다.

1. 계획수립추진과정

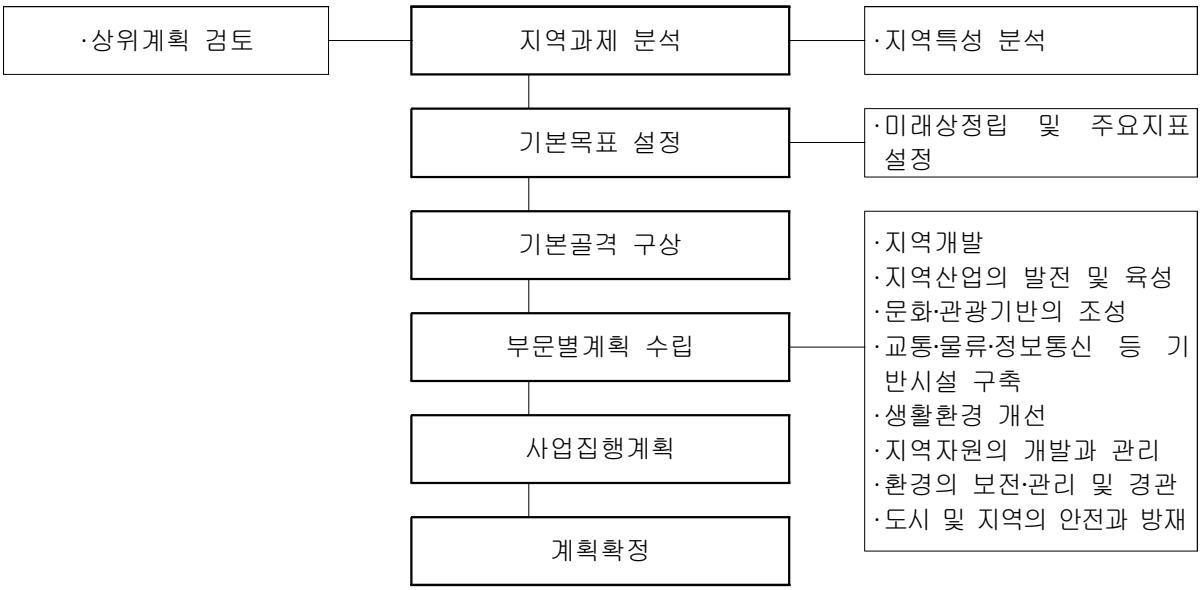

2. 과업수행추진과정

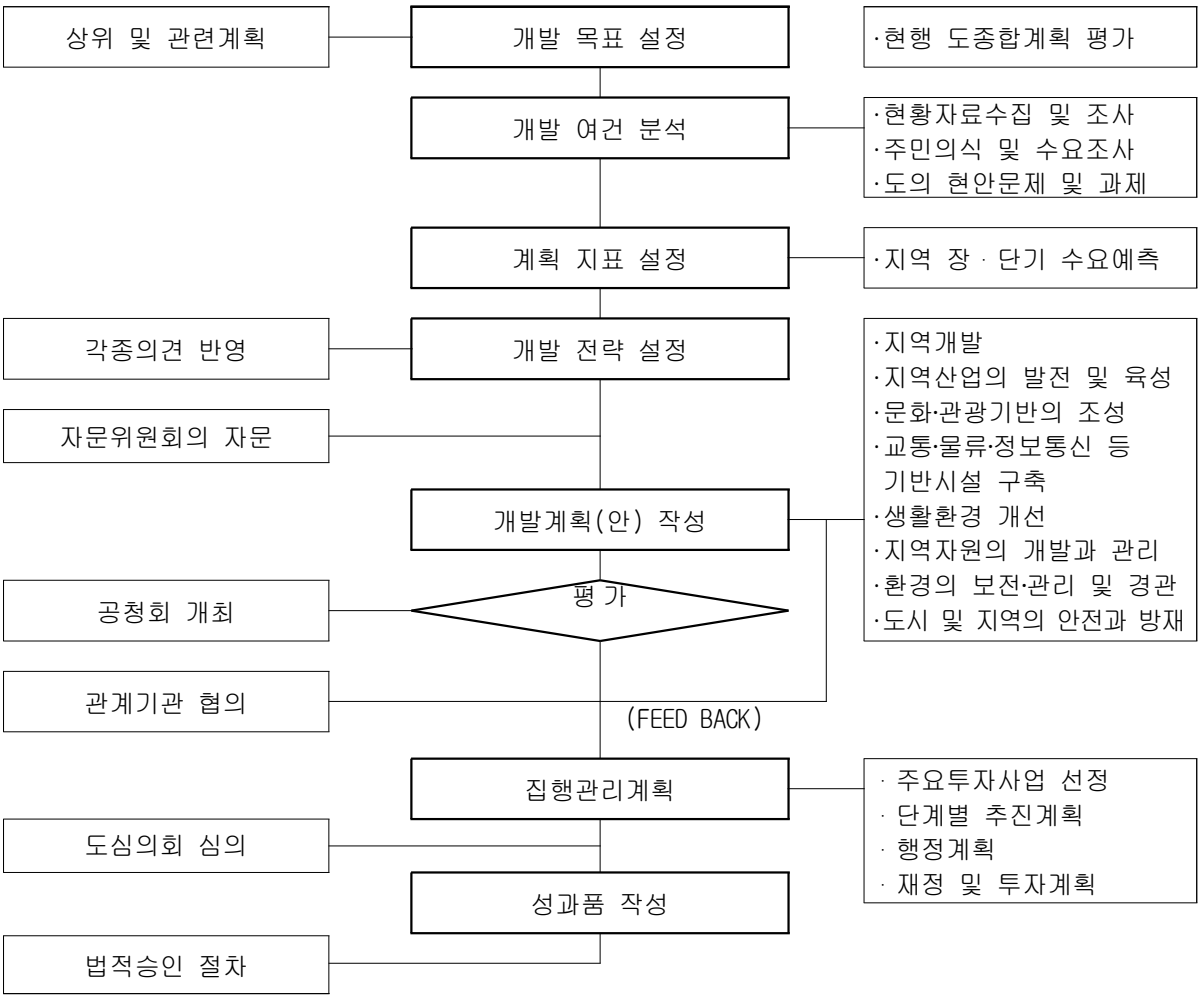

3-4 품 산정의 기준

○ 도 종합계획의 품 산정은 업무성격상 계획수립기간의 장기간 소요 및 계획업무의 특수성, 특정분야 연구의 필요성 등으로 다른 계획과 유사하게 산정하기가 난이(難易)하므로, 업무범위, 추진과정 등만을 수록하여 업무추진에 참고가 되도록 하였으며, 직접인건비 등에 관한 품 산정은 과업의 특수성을 충분히 감안하여 발주자와 엔지니어링사업자가 협의 결정하되 관련 유사부분을 준용 산정토록 한다.

제4절 지역계획

4-1 정 의

○ 국토의 건전한 발전과 국민의 복리향상에 이바지하기 위해 지역특성에 맞는 정비나 개발을 위하여 세우는 계획을 말하며, 지역의 특성에 따라 수도권발전계획, 광역권개발계획, 특정지역개발계획, 개발촉진지구개발계획 등으로 구분한다.

4-2 자료제공의 전제

○ 당해 계획의 수립에 필요한 모든 관련자료는 원칙적으로 발주자가 제공하는 것으로 하되, 보유하지 않는 자료는 엔지니어링사업자가 수집한다.

○ 발주자가 제공하지 못하는 자료의 조사에 있어서는 그 규모·내용에 의거하여 별도의 엔지니어링사업대가를 산정하여 엔지니어링사업자가 수행하며, 당해 관련자료의 기밀성과 광범위한 자료가 요구되므로 조사·분석에 필요한 상당기간과 자료수집비용이 전제되어야 한다.

4-3 업무범위와 추진과정

4-3-1. 업무범위

○ 지역계획의 업무범위는 국토의 건전한 발전과 지역의 특성에 맞는 정비나 개발을 위해 정책목표 및 발전방향 제시와 이에 따른 계획의 집행 및 관리에 관한 내용을 포함하는 것으로 한다.

○ 지역계획의 인허가과정에서 별도 승인을 받아야 하는 2가지 이상의 업무가 복합적으로 수행될 때에는 발주자와 협의과정을 거쳐 별도의 엔지니어링 활동업무로 산정한다.

4-3-2. 추진과정

○ 타부처(관계기관)와의 협의나 전문가 자문, 공청회 및 의견청취, 정책심의회 등에 소요되는 기간은 과업수행기간에서 제외하여 그 소요기간 만큼 과업수행기간을 연장하여야 한다.

1. 계획수립추진과정

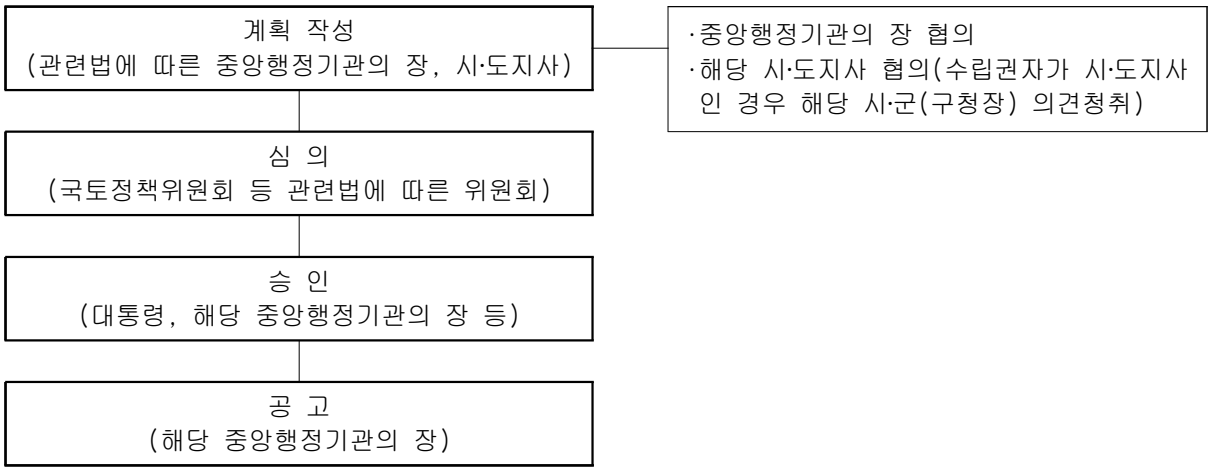

2. 과업수행추진과정

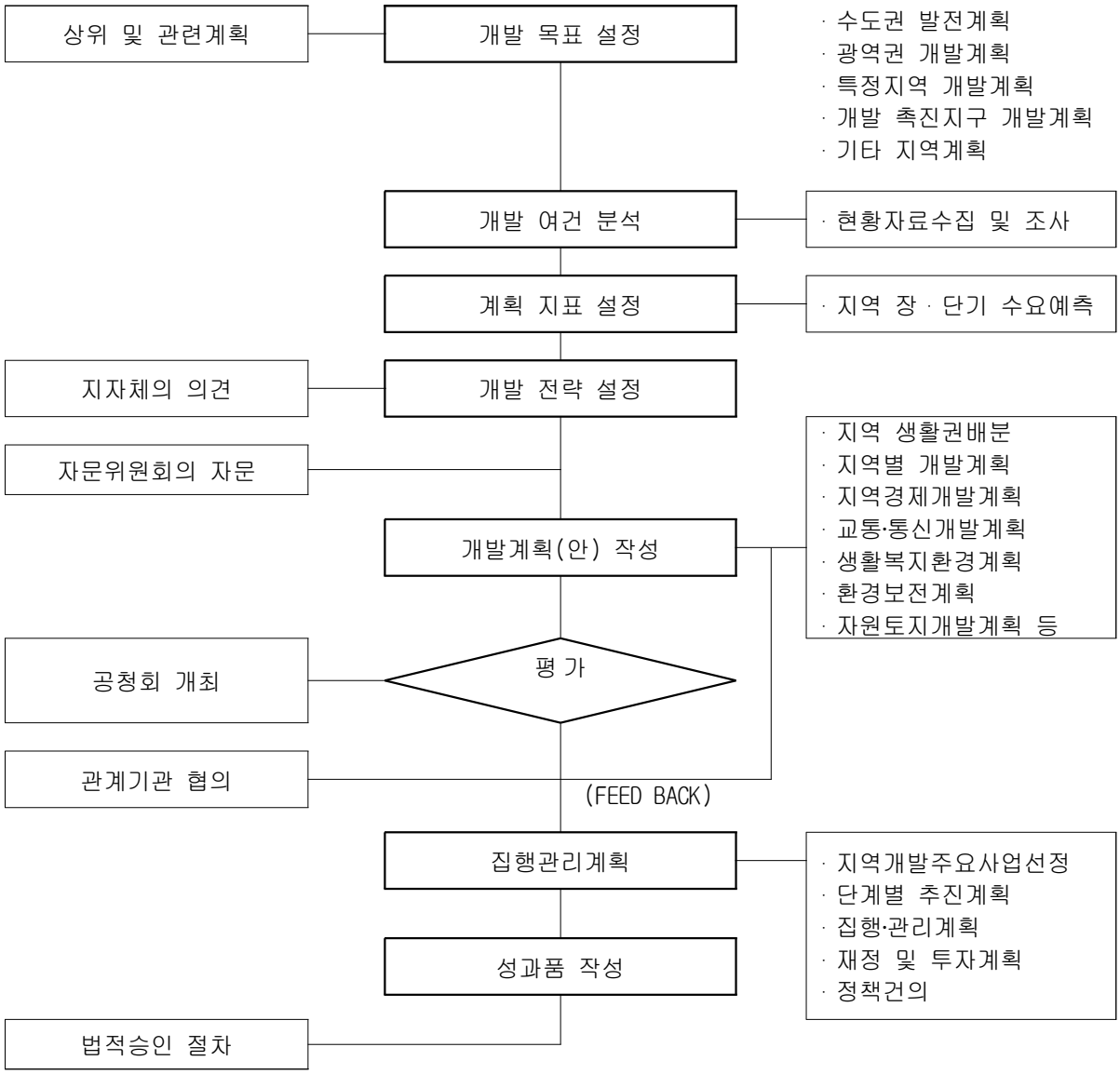

4-4 품 산정의 원단위 산정과 기준

4-4-1. 표준품 산정내역

○ 표준품 산정의 기준이 되는 비목은 제1장 총칙에서 제시한 비목을 중심으로 하였으며, 이는 지역계획에 필요한 사항만을 대상으로 한다.

○ 표준품 산정의 기본이 되는 직접인건비 품의 작업항목별 보할은 업무 난이도를 감안하여 설정토록 한다.

종별		내용	세부항목	단위	비고
직접비	직접인건비	1.지역현황조사	①자연환경조사 ②인문환경조사 ③산업구조조사 ④기반시설조사 ⑤부존자원조사 ⑥유통구조조사	인·일 〃 〃 〃 〃 〃	
		2.개발여건분석	①일반여건전망 ②장기사회경제전망 ③상위계획과의 상관성 ④지역의 발전여건	〃 〃 〃 〃	
		3.기본구상	①기본방향설정 ②종합개발목표설정 ③계획지표설정 ④지역생활권배분	〃 〃 〃 〃	
		4.부문별개발계획	①지역별 개발계획 ②지역경제개발계획 ③교통통신개발계획 ④생활복지환경계획 ⑤환경보전계획 ⑥자원토지개발계획	〃 〃 〃 〃 〃 〃	
		5.계획추진방안	①지역개발주요사업선정 ②단계별추진계획 ③집행 · 관리계획 ④행 · 재정계획 ⑤정책건의	〃 〃 〃 〃 〃	
		6.성과품작성	①보고서작성 및 편집 ②관련도서작성	〃 〃	
		7.기술협의	①공청회/주민설명회 ②주민간담회/시민계획단 ③위원회심의 지원 ④관계기관 협의	〃 〃 〃 〃	
	직접경비	여비, 인쇄비, 조감도, 회의준비비, 현장운영비 등		식	제1장 총칙참조
간접비	제경비	(직접인건비)×120%		〃	〃
	기술료	(직접인건비+제경비)×25%		〃	〃

주 : ①각종영향성검토 및 각종영향평가업무는 별도의 엔지니어링활동업무로 계상한다.
②도시·군관리계획(변경) 및 농지(산지)전용 등을 수반하는 업무가 있을 경우에는 별도 작업비를 계상한다.

4-4-2 산정기준

1. 계획·기준면적의 설정

○ 지역계획은 지역특성에 맞는 정비·개발을 목적으로 크게는 시·군을 아우르는 계획을 수립하므로 기준면적은 500㎢로 하고 최소기준면적은 300㎢로 하였으며, 직능별 직접 인력 소요 원단위는 (구)시·군건설종합계획표준품셈(안)의 투입기술자 비율을 감안하여 설정하였다.

○ 기준면적 대비 단위사업의 대상면적이 현저히 작을 경우 최소기준면적은 300㎢로 하되 과업의 특수성을 충분히 감안하여 발주자와 엔지니어링사업자가 협의 결정하되 관련 유사부분을 준용하여 산정토록 한다.

2. 표준품의 산정방법

○ 표준품의 적용에 있어 기준면적과 계획면적의 차이에 따른 품 산정은 아래의 수정식에 따라 기준면적의 소요작업량을 수정하여 산정한다.

○ 소요작업량 = 기준면적 소요작업량 × 면적보정계수(α)

3. 계획안의 수정과 과업중지에 따른 품 산정방법

○ 계획안이 작성되고 타부처(관계기관)와의 협의나 전문가 자문, 공청회 및 의견청취, 정책심의회 등 행정절차과정을 거쳐 계획안이 확정된 후 발주자의 사정에 의하여 계획안이 일부변경·재작업이 수행되는 경우에는 그 변경·재작업의 정도에 따라 엔지니어링사업대가의 50～100% 수준에서 비용을 추가 지급하여야 한다.

○ 과업수행 중 발주자의 사정에 따른 과업 중단으로 인해 정부 회계연도가 경과되어 현저한 비용의 차이가 발생하였을 경우에는 엔지니어링사업대가를 당해 신년도의 노임단가를 기준으로 재산정하여야 한다.

4-4-3 단위별 변화수정과 보정

1. 작업량 보정계수 산정

○ 계획기준면적을 초과하거나 못 미치는 경우의 직접인력 소요작업량의 산정을 위한 보정계수(α)는 다음의 식에 의해 산정한다.

$$\alpha = \left(\frac{\text{계획면적}}{\text{기준면적}}\right)^{0.5} = \left(\frac{A}{500}\right)^{0.5}$$

α = 보정계수
A = 계획면적(㎢)

계획단위 면적별 보정계수

계획면적(㎢)	보정계수(α)	계획면적(㎢)	보정계수(α)
300	0.775	800	1.265
400	0.894	900	1.342
500	1.000	1,000	1.414
600	1.095	1,100	1.483
700	1.183	1,200	1.549

주 : 계획면적이 300㎢ 미만인 경우에는 계획면적 300㎢를 기준으로 하여 산정한다.

2. 직접 인건비 소요 작업량 산정

○ 계획면적의 대소에 따른 직접인력 소요작업량의 산정방법은 아래와 같이 기준면적의 직능별 직접인력 소요작업량에 계획단위면적의 보정계수(α)를 곱하여 산출한다.

구 분	기준면적 (㎢)	총작업량(인·일)					
		기술사	특 급	고 급	중 급	초 급	보조원
지역계획	500	65.7α	105.1α	292.6α	438.2α	658.5α	955.6α

4-5 표준단위 업무분류와 원단위

기술업무의 직능별 직접인력 소요작업량 (면적500㎢ 기준)

(단위 : 인·일/표준단위)

구 분	업무내용	표준단위	소요인력						비고
			기술사	특 급	고 급	중 급	초 급	보조원	
1.지역현황조사	①자연환경조사	500㎢	1.5	2.4	7.0	14.5	28.3	49.7	
	②인문환경조사	500㎢	1.5	2.4	7.0	14.5	28.3	49.7	
	③산업구조조사	500㎢	1.8	2.9	7.0	14.5	27.0	46.8	
	④기반시설조사	500㎢	1.5	2.4	8.0	14.9	27.0	46.8	
	⑤부존자원조사	500㎢	1.6	2.4	8.0	14.9	27.0	46.8	
	⑥유통구조조사	500㎢	2.0	3.2	7.0	14.5	27.0	46.8	
	소 계		9.9	15.7	44.0	87.8	164.6	286.6	
2.개발여건분석	①일반여건전망	500㎢	2.0	3.2	9.5	11.4	24.3	22.9	
	②장기사회경제전망	500㎢	2.2	3.7	8.8	10.5	24.3	22.9	
	③상위계획과의 상관성	500㎢	2.0	3.2	8.8	10.5	25.7	26.8	
	④지역의 발전여건	500㎢	2.0	3.2	9.5	11.4	24.3	22.9	
	소 계		8.2	13.3	36.6	43.8	98.6	95.5	
3.기본구상	①기본방향설정	500㎢	2.6	4.1	10.7	10.5	15.8	22.9	
	②종합개발목표설정	500㎢	2.1	3.4	11.7	12.3	15.8	22.9	
	③계획지표설정	500㎢	2.4	3.9	10.7	10.5	15.8	22.9	
	④지역생활권배분	500㎢	2.8	4.4	10.7	10.5	18.4	26.8	
	소 계		9.9	15.8	43.8	43.8	65.8	95.5	
4.부문별 개발계획	①지역별 개발계획	500㎢	5.0	8.0	20.3	28.4	32.3	46.8	
	②지역경제개발계획	500㎢	4.3	6.8	21.0	29.7	32.3	46.8	
	③교통통신개발계획	500㎢	4.3	6.8	21.0	29.7	32.3	46.8	
	④생활복지환경계획	500㎢	4.2	6.7	21.0	29.7	32.3	46.8	
	⑤환경보전계획	500㎢	4.2	6.8	20.0	28.0	36.2	52.6	
	⑥자원토지개발계획	500㎢	4.3	6.8	21.0	29.7	32.3	46.8	
	소 계		26.3	41.9	124.3	175.2	197.7	286.6	
5.계획추진방안	①지역개발주요사업선정	500㎢	1.2	2.0	5.3	8.3	13.2	9.6	
	②단계별추진계획	500㎢	1.2	2.0	6.7	9.2	13.2	9.6	
	③집행 · 관리계획	500㎢	1.3	2.0	6.7	9.7	13.2	9.6	
	④행 · 재정계획	500㎢	2.2	3.5	5.3	8.3	13.2	9.6	
	⑤정책건의	500㎢	2.3	3.6	5.3	8.3	13.2	9.6	
	소 계		8.2	13.1	29.3	43.8	66.0	48.0	
6.성과품작성	①보고서작성 및 편집	500㎢	1.9	3.2	6.3	21.5	32.2	71.7	
	②관련도서작성	500㎢	1.3	2.1	8.3	22.3	33.6	71.7	
	소 계		3.2	5.3	14.6	43.8	65.8	143.4	
총 계			65.7	105.1	292.6	438.2	658.5	955.6	
7.기술협의	①공청회/주민설명회	1식	2.0	2.0	2.0	4.0	4.0	4.0	주1
	②주민간담회/시민계획단	1식	2.0	2.0	2.0	4.0	4.0	4.0	
	③위원회심의 지원	1식	2.0	2.0	2.0	4.0	4.0	4.0	
	④관계기관 협의	1식	2.0	2.0	2.0	4.0	4.0	4.0	
	소 계		8.0	8.0	8.0	16.0	16.0	16.0	

주: ①기술협의는 2회 이내 기준이며, 횟수가 늘어날 경우 증가배수에 해당하는 작업품과 비용을 가산한다. (필요항목 선택적 적용)

②각종영향성검토 및 각종영향평가업무는 별도의 엔지니어링활동업무로 계상한다.

③과업의 특수성에 따라 상기내용에 없는 업무내용 발생 시 발주자와 엔지니어링사업자가 협의 결정하되 유사부분을 준용하여 산정할 수 있다.

4-6 주요업무내용

구 분	업무내용	내 용
1.지역현황조사	①자연환경조사	·수문, 표고, 경사도 등 지형지세 조사 ·강수량, 기온, 천기일수, 풍향 등 기상조사 ·기타 토양, 식생, 경관조사
	②인문환경조사	·인구규모, 인구구조, 인구분포 및 인구의 지역간 이동 등 인구조사 ·세력권, 지역간 연결, 도시와 농ㆍ어촌의 분포 등 정주구성 체계분석 ·지역별, 용도별 토지이용 현황조사 ·지역의 개발잠재력, 개발제약성 및 역사성 등 지역성격 조사분석
	③산업구조조사	·산업별구조, 총생산량(액) 규모 및 산업시설 등 산업구조조사 ·경제활동인구, 취업률, 실업률 등 고용실태조사 ·지역생산, 주민소득, 소득배분, 가구소득 등 주민계정조사
	④기반시설조사	·교통수단, 교통량, 교통시설 및 도로포장률, 도로개설률, 도로의 지역간 연계성 등 교통환경조사 ·전화보급률, 전신이용률 및 전력수급 등 통신 및 에너지 관련시설조사 ·주택, 상하수도, 분뇨진개 등 생활환경시설조사 ·의료시설, 복지시설, 환경오염, 재해방재 등 사회복지시설조사 ·교육시설, 문화시설, 체육시설 등 교육문화시설조사
	⑤부존자원조사	·토지자원, 수자원, 지하자원, 산림자원 등 자연자원조사 ·관광지, 공원 및 지방문화재, 토산품 등 관광자원 조사
	⑥유통구조조사	·지역간 재화, 용역의 이동, 반출입품목 및 수량 등 물동량조사 ·도매시장, 소매시장, 농수산공판장, 농수산물집하장 등 유통시설 조사
2.개발여건분석	①일반여건전망	·개발을 위한 기본전제 설정 ·지방행정제도의 변화전망 ·개발투자여건의 변화전망 ·정책적 제반여건의 변화전망
	②장기사회경제전망	·인구구조 및 규모와 인구이동의 전망 ·산업별구조 및 생산량(액)의 변화전망 ·지역주민의 의식구조변화전망(설문조사 및 분석)
	③상위계획과의 상관성	·국토종합계획, 도종합계획 등 상위계획과의 상관성 검토
	④지역의 발전여건	·개발잠재력 분석 ·개발저해요인 분석 ·농산어촌지역개발을 위한 방안
3.기본구상	①기본방향설정	·계획의 변경 ·목표년도 및 개발단계의 설정 ·계획의 기본방향 설정

구 분	업무내용	내 용
3.기본구상	②종합개발목표설정	·기본이념 및 목표의 설정 ·개발목표 및 전략의 설정 ·개발의 기본구상 및 대안의 설정
	③계획지표설정	·인구규모, 인구구조 등 인구에 관한 지표의 설정 ·경제산업구조, 생산량(액) 및 소득소비구조 등 산업경제 지표의 설정 ·의료, 복지, 주택, 학교 및 기반시설 등 생활환경 지표의 설정
	④지역생활권배분	·지방 및 농·산·어촌중심도시의 설정 ·정주생활권의 구성 ·생활권별 인구배분
4.부문별 개발계획	①지역별 개발계획	·도시개발계획 ·농·산·어촌개발계획 ·특수지역개발계획
	②지역경제개발계획	·농림수산업 진흥계획 ·지방산업 확충계획 ·지역서비스산업 육성계획
	③교통통신개발계획	·교통망 정비 및 확충 ·통신망 정비 및 확충
	④생활복지환경계획	·주택 및 택지공급계획 ·상·하수도시설계획 ·보건·의료시설계획 ·사회·복지시설계획 ·교육·문화·체육시설계획
	⑤환경보전계획	·환경보전 및 관리계획 ·재해방지계획
	⑥자원토지개발계획	·용수개발계획 ·관광·위락자원개발 ·에너지 및 지하자원개발 ·토지이용 및 관리계획
5.계획추진방안	①지역개발주요사업선정	·개발사업비의 산정 ·경제타당성 분석 ·개발의 우선순위결정
	②단계별추진계획	·단계별 투자계획 ·단계별 추진계획
	③집행 · 관리계획	·단계별 집행계획 ·관리운영계획
	④행 · 재정계획	·지방행정분석, 계층조정 및 구역개편, 행정기구 및 조직개편 등 행정 개선계획 ·지방재정실태분석 및 재원조달방안
	⑤정책건의	·계획추진의 목표달성을 위한 건의

4-7 표준성과품

성과구분	표준성과도서			비 고
	구 분	규 격	제출부수	
현황도	· 위치도 · 토지이용현황도 · 주요시설현황도 · 현황종합분석도	1/5,000 1/5,000 1/5,000 1/5,000	1부 1부 1부 1부	
계획도	· 지구계 또는 구역계 설정도 · 지역별개발 계획도 · 기반시설계획도 · 교통계획도 · 종합계획도	1/1,200~1/5,000 1/5,000 1/5,000 1/5,000 1/5,000	1부 1부 1부 1부 1부	
보고서 (결정조서 포함)	· 지구지정 및 지역계획 보고서 · 심의용 보고서	A4 A4	30부 1식	
참고도서	· 의견청취 조치내용 및 관계기관 협의 등 지구지정 및 지역계획 수립시 이용된 자료		1식	발주자와 협의
CD	· 자료CD		1식	

주: ①제출부수 및 성과품 종류가 증가할 경우에는 증가배수에 해당하는 작업품과 비용을 가산한다.
②축적 1/1,200~1/5,000의 기본도를 발주자에서 제공하지 않을 경우에는 조사측량 후 지도제작비를 별도 계상한다.

제5절 농·산·어촌계획

5-1 정 의

○ 농·산·어촌계획이라 함은 국토계획·부문별계획·도종합계획·시군종합계획·지역계획 등의 포괄적인 계획에 따라 지정·개발·정비하고자 하는 지역에 대하여 수립하는 일반농·산·어촌개발계획과 취락지구개발계획 등을 말한다.

○ 일반농·산·어촌개발계획이라 함은 국가균형발전특별법, 농림어업인 삶의 질 향상 및 농·산·어촌지역 개발촉진에 관한 특별법, 농·어·촌정비법, 지방소도읍육성 지원법, 임업 및 산촌 진흥촉진에 관한 법률 등에 의하여 지정·조성·정비되는 당해 지역에 대한 제시설의 개발·시행·설계를 말한다.

○ 취락지구개발계획이라 함은 국토의 계획 및 이용에 관한 법률에 의한 녹지지역・관리지역・농림지역・자연환경보전지역・개발제한구역 또는 도시자연공원구역안의 취락을 정비하기 위한 취락지구의 지정과 취락지구의 정비계획을 말한다.

5-2 자료제공의 전제

○ 당해 계획의 수립에 필요한 모든 관련자료는 원칙적으로 발주자가 제공하는 것으로 하되, 보유하지 않는 자료는 엔지니어링사업자가 수집한다.

○ 발주자가 제공하지 못하는 자료의 조사에 있어서는 그 규모·내용에 의거하여 별도의 엔지니어링사업대가를 산정하여 엔지니어링사업자가 수행하며, 당해 관련자료의 기밀성과 광범위한 자료가 요구되므로 조사·분석에 필요한 상당기간과 자료수집비용이 전제되어야 한다.

5-3 업무범위와 추진과정

5-3-1 업무범위

○ 농·산·어촌계획의 업무범위는 당해 지구의 효율적인 이용과 관리에 관한 계획 및 제도적 개선방안 제시와 이에 따른 계획의 집행 및 관리에 관한 내용을 포함하는 것으로 한다. 단 특별한 평가업무는 별도의 과업으로 한다.

○ 인허가과정에서 별도 승인을 받아야 하는 2가지 이상의 업무가 복합적으로 수행될 때에는 발주자와 협의과정을 거쳐 별도의 엔지니어링활동업무로 산정한다.

구 분	내 용		별도비용 산정
일반 농·산·어촌 개발*	읍·면소재지 종합정비	농·산·어촌 거점지역의 육성 (소도읍육성사업, 거점면소재지정비사업)	총괄계획가(MP) 운영 직접경비 별도산정 교육(지역역량강화) 학술용역 원가계산 별도산정 도시·군관리계획(변경) 엔지니어링사업 대가 별도산정
	권역단위 종합정비	특성이 같은 2개 이상 마을을 하나의 권역으로 묶어 정비 (농·어·촌종합개발사업, 산촌개발사업)	
	신규마을 조성 및 재개발	농·산·어촌지역의 새로운 마을 조성 및 기존마을의 정비에 관한 마을정비계획 수립 및 마을정비구역의 지정	
	기초생활 인프라정비	농·산·어촌 생활환경정비, 농·산·어촌 생산기반 조성, 마을공동소득 및 공공문화조성	
취락지구 개발	국토의 계획 및 이용에 관한 법률에 의한 녹지지역·관리지역·농림지역·자연환경보전지역·개발제한구역 또는 도시자연공원구역안의 취락지구의 지정 및 개발		

주 : 일반농산어촌 개발업무는 관련 매뉴얼 기준 준용

5-3-2 추진과정

○ 타부처(관계기관)와의 협의나 전문가 자문, 공청회 및 의견청취 등에 소요되는 기간은 과업수행기간에서 제외하여 그 소요기간 만큼 과업수행기간을 연장하여야 한다.

1. 계획수립추진과정

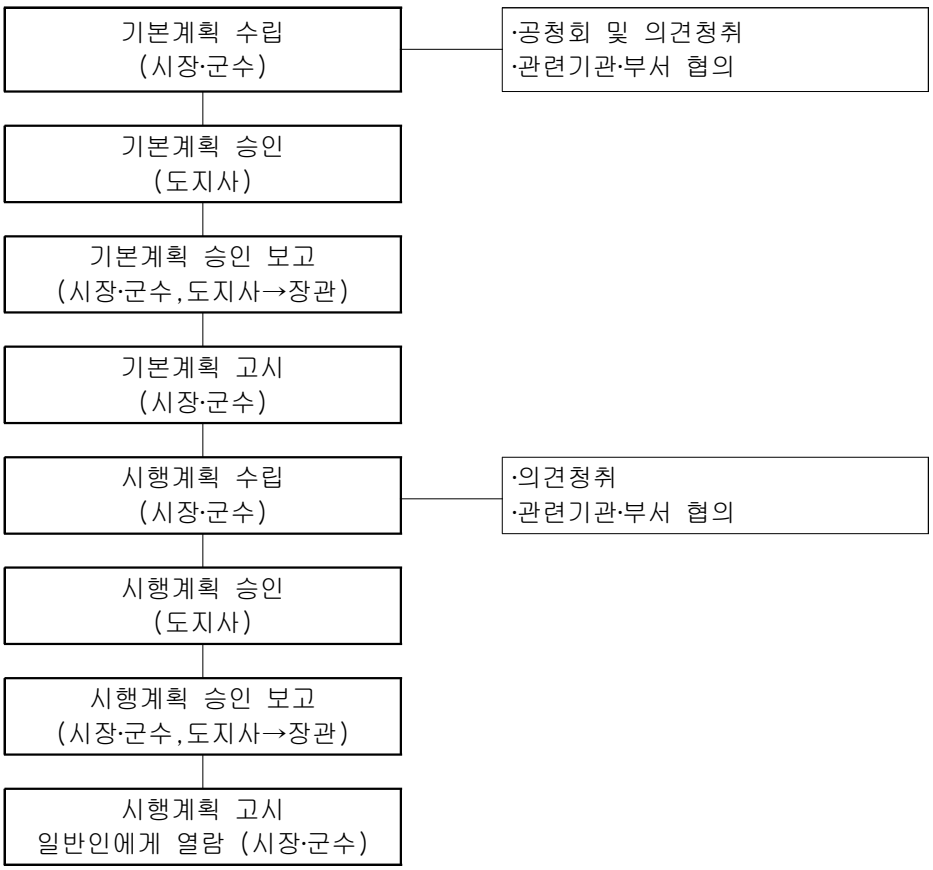

2. 과업수행추진과정

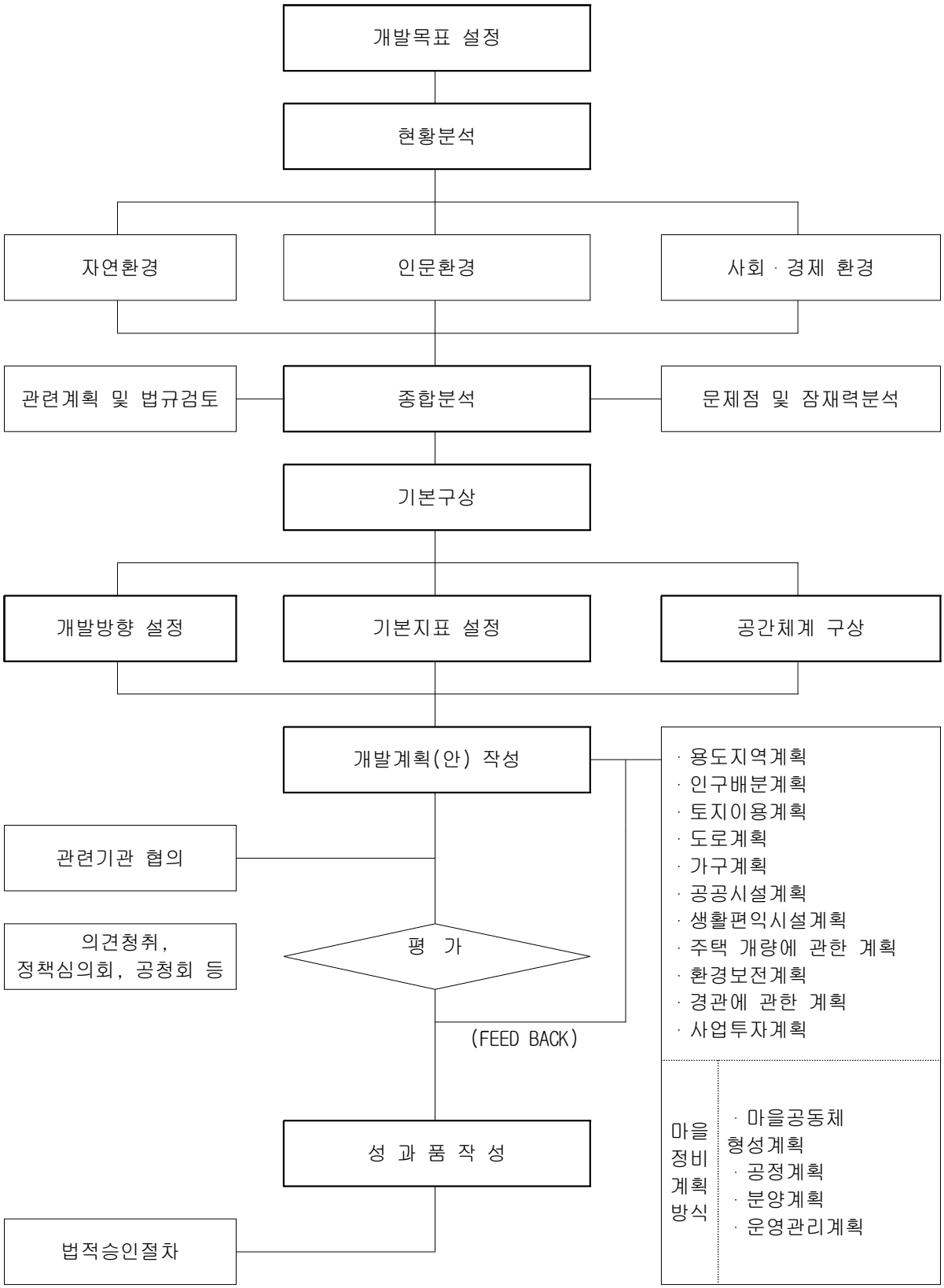
개발목표 설정
현황분석
자연환경
인문환경
사회 · 경제 환경
관련계획 및 법규검토
종합분석
문제점 및 잠재력분석
기본구상
개발방향 설정
기본지표 설정
공간체계 구상
개발계획(안) 작성
· 용도지역계획
· 인구배분계획
· 토지이용계획
· 도로계획
· 가구계획
· 공공시설계획
· 생활편익시설계획
· 주택 개량에 관한 계획
· 환경보전계획
· 경관에 관한 계획
· 사업투자계획
관련기관 협의
의견청취,
정책심의회, 공청회 등
평 가
(FEED BACK)
마을 정비 계획 방식
· 마을공동체 형성계획
· 공정계획
· 분양계획
· 운영관리계획
성 과 품 작 성
법적승인절차

5-4 품 산정의 원단위 산정과 기준

5-4-1 표준품 산정내역

○ 표준품 산정의 기준이 되는 비목은 제1장 총칙에서 제시한 비목을 중심으로 하였으며, 이는 농·산·어촌계획에 필요한 사항만을 대상으로 한다.

○ 표준품 산정의 기준이 되는 직접인건비 품의 작업항목별 보할은 업무의 난이도를 감안하여 설정토록 한다.

종 별		내 용	세부항목	단 위	비 고
직접비	직접인건비	1.기본자료 수집 및 현황분석	①자연환경자료 수집정리 ②인문·경제·사회환경 자료 수집정리 ③관련계획자료 수집정리 ④현황자료분석 및 평가	인·일 〃 〃 〃	
		2.기본구상	①계획의 배경과 목표설정 ②개발지표설정 ③개발기본구상	〃 〃 〃	
		3.개발계획	①용도지역계획 ②인구배분계획 ③토지이용계획 ④도로계획 ⑤가구계획 ⑥공공시설계획 ⑦생활편의시설계획 ⑧주택 개량에 관한 계획 ⑨환경보전계획 ⑩경관에 관한 계획 ⑪사업투자계획	〃 〃 〃 〃 〃 〃 〃 〃 〃 〃 〃	
		마을정비 계획방식	⑫마을공동체 형성계획 ⑬공정계획 ⑭분양계획 ⑮운영관리계획	〃 〃 〃 〃	
		4.성과품작성	①보고서작성 및 편집 ②관련도서작성	〃 〃	
		5.기술협의	①공청회/주민설명회 ②주민간담회/시민계획단 ③위원회심의 지원 ④관계기관 협의	〃 〃 〃 〃	주1
	직접경비	여비, 인쇄비, 조감도, 회의준비비, 현장운영비 등		식	제1장 총칙참조
간접비	제경비	(직접인건비)×120%		〃	〃
	기술료	(직접인건비+제경비) ×25%		〃	〃

주 : ①기술협의는 2회 이내 기준이며, 횟수가 늘어날 경우 증가배수에 해당하는 작업품과 비용을 가산한다. (필요항목 선택적 적용)

②각종영향성검토 및 각종영향평가업무는 별도의 엔지니어링활동업무로 계상한다.

③도시·군관리계획(변경) 및 농지(산지)전용 등을 수반하는 업무가 있을 경우에는 별도 작업비를 계상한다.

④기본설계 및 실시설계의 산출기준은 엔지니어링사업대가 기준 중 건설부문 공사비 요율을 적용한다.

5-4-2 산정기준

1. 계획·기준면적의 설정

○ 농·산·어촌계획은 사업규모 상 면급(面給) 도시보다 작은 국지적인 개발계획으로서 주택단지 개발계획과 업무내용이 유사하므로, 기준면적을 20만㎡로 하였으며, 직능별 직접인력 소요 원단위는 기 작성된 취락지구개발계획 등의 투입기술자 비율을 감안하여 설정하였다.

○ 계획면적은 고시된 면적을 원칙으로 한다.

2. 표준품의 산정방법

○ 표준품의 적용에 있어 기준면적과 계획면적의 증감에 따른 품 산정은 아래의 수정식에 따라 기준면적의 소요작업량을 수정하여 산정한다.

○ 소요작업량 = 기준면적 소요작업량 × 면적보정계수(α)

3. 계획안의 수정과 과업중지에 따른 품 산정방법

○ 계획안이 작성되고 주민공람, 의회보고 등 행정절차과정을 거쳐 계획안이 확정된 후 발주자의 사정에 의하여 계획안이 일부변경 · 재작업이 수행되는 경우에는 그 변경·재작업의 정도에 따라 엔지니어링사업대가의 50～100% 수준에서 비용을 추가 지급하여야 한다.

○ 과업수행 중 발주자의 사정에 따른 과업 중단으로 인해 정부 회계연도가 경과되어 현저한 비용의 차이가 발생하였을 경우에는 엔지니어링사업대가를 당해 신년도의 노임단가를 기준으로 재산정하여야 한다.

5-4-3 단위별 변화수정과 보정

1. 면적의 대소에 대한 작업량 보정계수 산정

○ 계획기준면적을 초과하거나 못 미치는 경우의 직접인력 소요작업량의 산정을 위한 보정계수(α)는 다음의 식에 의해 산정한다.

$$\alpha = \left(\frac{\text{계획면적}}{\text{기준면적}}\right)^{0.6} = \left(\frac{A}{20}\right)^{0.6}$$

α = 보정계수
A = 계획면적(만㎡)

계획단위 면적별 보정계수

계획면적(만㎡)	보정계수 (α)	계획면적(만㎡)	보정계수 (α)
3	0.339	60.0	1.933
5	0.435	80.0	2.297
10	0.660	100.0	2.627
20	1.000	150.0	3.350
40	1.516	200.0	3.981

주 : 계획면적이 3만㎡ 미만인 경우에는 계획면적 3만㎡를 기준으로 하여 산정한다.

2. 직접 인건비 소요 작업량 산정

○ 계획면적의 대소에 따른 직접인력 소요작업량의 산정방법은 아래와 같이 기준면적의 직능별 직접인력 소요작업량에다 계획단위면적의 보정계수(α)를 곱하여 산출한다.

구 분	기준면적 (만㎡)	총작업량(인·일)					
		기술사	특급	고급	중급	초급	보조원
농산어촌계획	20	16.4α	26.3α	66.3α	100.7α	175.7α	211.4α
마을정비 계획방식	20	21.6α	34.3α	87.5α	132.7α	231.7α	279.0α

5-5 표준단위 업무분류와 원단위

5-5-1 기본계획

기술업무의 직능별 직접인력 소요작업량 (면적20만㎡ 기준)

(단위 : 인·일/표준단위)

구 분	업무내용	표준단위	소요인력						비고
			기술사	특 급	고 급	중 급	초 급	보조원	
1.기본자료 수집 및 현황분석	①자연환경자료 수집정리	20만㎡	0.2	0.4	0.9	1.7	3.0	4.4	
	②인문·경제·사회환경, 자료 수집정리	20만㎡	0.2	0.4	0.9	1.7	3.0	4.4	
	③관련계획자료 수집정리	20만㎡	0.2	0.4	0.9	1.7	3.0	4.4	
	④현황자료분석 및 평가	20만㎡	0.2	0.4	1.1	1.7	3.0	4.4	
	소 계		0.8	1.6	3.8	6.8	12.0	17.6	
2.기본구상	①계획의 배경과 목표설정	20만㎡	0.6	1.0	1.6	2.2	3.8	4.6	
	②개발지표 설정	20만㎡	0.6	1.0	1.6	2.2	3.8	4.6	
	③개발 기본구상	20만㎡	0.7	1.1	2.0	2.4	4.2	4.9	
	소 계		1.9	3.1	5.2	6.8	11.8	14.1	
3.개발계획	①용도지역계획	20만㎡	1.3	2.1	5.6	8.5	14.7	16.9	주1 주2
	②인구배분계획	20만㎡	1.3	2.1	5.6	8.5	14.7	16.9	
	③토지이용계획	20만㎡	1.3	2.1	5.6	8.5	14.7	16.9	
	④도로계획	20만㎡	1.3	2.1	5.6	8.5	14.7	16.9	
	⑤가구계획	20만㎡	1.3	2.0	5.3	8.0	14.0	16.9	
	⑥공공시설계획	20만㎡	1.3	2.0	5.3	8.0	14.0	16.9	
	⑦생활편익시설계획	20만㎡	1.3	2.0	5.3	8.0	14.0	16.9	
	⑧주택 개량에 관한 계획	20만㎡	1.3	2.0	5.3	8.0	14.0	16.9	
	⑨환경보전계획	20만㎡	1.3	2.1	5.4	8.1	14.2	17.0	
	⑩경관에 관한 계획	20만㎡	-	-	-	-	-	-	
	⑪사업투자계획	20만㎡	1.3	2.1	5.6	8.4	14.7	17.7	
	⑫마을공동체 형성계획	20만㎡	1.3	2.0	5.3	8.0	14.0	16.9	마을정비 계획방식
	⑬공정계획	20만㎡	1.3	2.0	5.3	8.0	14.0	16.9	
	⑭분양계획	20만㎡	1.3	2.0	5.3	8.0	14.0	16.9	
	⑮운영관리계획	20만㎡	1.3	2.0	5.3	8.0	14.0	16.9	
	소 계		13.0	20.6	54.6	82.5	143.7	169.9	
			18.2	28.6	75.8	114.5	199.7	237.5	마을정비 계획방식
4.성과품 작성	①보고서작성 및 편집	20만㎡	0.5	0.7	1.6	2.1	3.0	2.7	
	②관련도서작성	20만㎡	0.2	0.3	1.1	2.5	5.2	7.1	
	소 계		0.7	1.0	2.7	4.6	8.2	9.8	
총 계			16.4	26.3	66.3	100.7	175.7	211.4	
			21.6	34.3	87.5	132.7	231.7	279.0	마을정비 계획방식
5.기술협의	①공청회/주민설명회	1식	2.0	2.0	2.0	4.0	4.0	4.0	주3
	②주민간담회/시민계획단	1식	2.0	2.0	2.0	4.0	4.0	4.0	
	③위원회심의 지원	1식	2.0	2.0	2.0	4.0	4.0	4.0	
	④관계기관 협의	1식	2.0	2.0	2.0	4.0	4.0	4.0	
	소 계		8.0	8.0	8.0	16.0	16.0	16.0	

주 : ①환경영향평가 등의 내용을 계획에 반영하기 위한 작업만을 범위로 한다.

②경관에 관한 계획은 제7장 도시경관품셈을 적용한다.

③기술협의는 2회 이내 기준이며, 횟수가 늘어날 경우 증가배수에 해당하는 작업품과 비용을 가산한다. (필요항목 선택적 적용)

④각종영향성검토 및 각종영향평가업무는 별도의 엔지니어링활동업무로 계상한다.

5-5-2 (사업)시행계획

○ 사업시행계획의 산출기준은 제6장 도시재생 중 제3절 도시 및 주거환경정비계획의 사업시행계획 및 관리처분계획 업무를 준용한다. 단, 환지방식으로 시행하는 경우 산출기준은 제5장 도시개발 중 제2절 환지방식 개발계획 업무를 준용한다.

5-5-3 기본설계 및 실시설계

○ 기본설계 및 실시설계의 산출기준은 엔지니어링사업대가의 기준 중 건설부문 공사비 요율을 적용한다.

5-6 주요업무내용

구 분	업무내용	내 용
1.기본자료수집 및 현황분석	①자연환경자료 수집·정리	·수문, 표고, 경사도 등 지형지세조사 ·강수량, 기온, 천기일수, 풍향 등 기상조사 ·기타 토양, 식생, 경관조사
	②인문·사회환경자료 수집·정리	·인구 및 가구조사 ·지목별, 용도별 토지이용 현황조사 ·기반시설 조사 ·농업, 산림, 어업, 주민소득, 관광자원 현황 등 ·토지확보, 입주예정자 현황 등
	③관련계획자료 수집·정리	·상위 관련계획과의 상관성 검토
	④현황자료 분석 및 평가	·지구의 개발잠재력, 개발제약성 등 분석평가
2.기본구상	①계획의 배경과 목표설정	·계획의 배경, 개발목표 및 기본방향 설정
	②개발지표의 설정	·인구 및 가구에 관한 지표 설정 ·토지용도 및 생활환경지표의 설정
	③개발기본구상	·공간구성구상 ·토지이용구상 ·동선체계구상 ·녹지체계구상
3.개발계획	①용도지역계획	·지구 성격에 따른 용도지역의 설정
	②인구배분계획	·지구내 적정 인구 배분 계획수립
	③토지이용계획	·구체적인 토지이용계획 수립
	④도로계획	·지구내 위계별 도로계획 수립
	⑤가구(街區)계획	·기존대지규모 및 용도에 적합한 가구분할계획 수립
	⑥공공시설계획	·기반시설의 설치 및 정비 계획수립
	⑦생활편의시설계획	·부대복리시설의 계획수립
	⑧주택 개량에 관한 계획	·주택배치 기본방향 ·주택건축 일정 ·주택건축 방법 ·주택의 형태, 규모, 높이 등

구 분	업무내용		내 용
3.개발계획 (계속)	⑨환경보전계획		·환경보전 및 관리계획 ·재해방지계획
	⑩경관에 관한 계획		·경관계획 기본방향 ·경관형성을 위한 색채 가이드라인 ·지역별, 요소별 색채계획 ·경관을 고려한 건축물 높이 및 단지배치 등
	⑪사업투자계획		·소요사업비의 추정 ·단계별 시행계획, 공공투자 계획
	마을정비 계획방식	⑫마을공동체 형성계획	·입주자를 위한 소득 ·지역융화 프로그램계획 ·생활서비스 연계방안 제시
		⑬공정계획	·부문별 공정계획
		⑭분양계획	·분양시설물 내역 ·분양방법 등
		⑮운영관리계획	·전원생활 프로그램 ·경관계획 실행방안 ·공동체 형성방안 ·지역발전 기여방안 등

5-7 표준성과품

성과구분	표준성과도서			비 고
	구 분	규 격	제출부수	
현황도	· 토지이용현황도 · 주요시설분포현황도	1/3,000～1/5,000 1/3,000～1/5,000	1부 1부	
계획도	· 도로망계획도 · 가구계획도 · 토지이용계획도 · 공공 및 생활편의시설계획도 · 주택개량에 관한 계획도 · 종합계획도	1/1,200～1/5,000 1/1,200～1/5,000 1/1,200～1/5,000 1/1,200～1/5,000 1/1,200～1/5,000 1/1,200～1/5,000	1부 1부 1부 1부 1부 1부	
보고서 (결정조서포함)	· 농·산·어촌계획보고서 · 심의용 보고서	A4 A4	30부 1식	
참고도서	· 의견청취 조치내용 · 농·산·어촌계획 수립에 이용된 자료		1식	발주자와 협의
CD	· 자료CD		1식	

주 : ①제출부수 및 성과품 종류가 증가할 경우에는 증가배수에 해당하는 작업품과 비용을 가산한다.
②축적 1/1,200～1/3,000의 기본도를 발주자에서 제공하지 않을 경우에는 조사측량 후 지도제작비를 별도 계상한다.

제3장 도시계획

제1절 광역도시계획
제2절 도시·군기본계획
제3절 도시·군관리계획
제4절 도시(지역)교통계획
제5절 지형도면고시계획
제6절 단계별집행계획
제7절 개발제한구역 관리계획
제8절 도시계획 기초조사
제9절 성장관리방안
제10절 개발행위허가
제11절 도시방재계획
제12절 저탄소 녹색도시계획

제1절 광역도시계획

1-1 정 의

○ 광역도시계획은 도시의 범위와 기능이 행정구역을 넘어 외연적으로 확산되고 연담화(連擔化)됨에 따라 인접한 2 이상의 도시 및 주변지역을 하나의 도시권으로 설정하여 장기적인 발전방향과 전략을 제시하고 도시간의 기능을 상호 연계함으로써 적정한 성장관리와 쾌적한 도시환경을 조성하여 광역도시권의 지속 가능한 발전을 도모하기 위한 계획이며, 도시계획체계상의 최상위계획으로서 도시 · 군기본계획 및 도시·군관리계획 등의 하위계획에 대한 지침이 되는 도시정책방향을 체계화하는 계획이다.

1-2 자료제공의 전제

○ 당해 계획의 수립에 필요한 모든 관련자료는 원칙적으로 발주자가 제공하는 것으로 하되, 보유하지 않는 자료는 엔지니어링사업자가 수집한다.

○ 발주자가 제공하지 못하는 자료의 조사에 있어서는 그 규모·내용에 의거하여 별도의 엔지니어링사업대가를 산정하여 엔지니어링사업자가 수행하며, 당해 관련자료의 기밀성과 광범위한 자료가 요구될 경우 조사·분석에 필요한 상당기간과 자료수집비용이 전제되어야 한다.

1-3 업무범위와 추진과정

1-3-1 업무범위

○ 환경적으로 건전하고 지속가능한 광역도시권의 발전을 위해 “광역도시계획 수립지침”에서 제시하고 있는 부문별 내용이 포함되는 계획을 수립하여야 한다. 다만, 특정부문 중심으로 계획을 수립하는 경우에는 해당부문에 대하여 중점적으로 계획을 수립할 수 있다.

○ 광역도시권내의 도시가 광역도시계획의 내용에 도시 · 군기본계획에 포함되는 내용을 추가하여 계획을 수립코자 하는 경우의 대가는 도시 · 군기본계획 표준품셈을 추가하여 반영토록 한다.

○ 광역도시권내에 개발제한구역이 포함되어 있을 경우에는 개발제한구역 조정계획과 개발제한구역에 대한 환경평가 검증을 업무범위에 포함시키도록 한다.

1-3-2 추진과정

○ 타부처(관계기관)와의 협의나 전문가 자문 등에 소요되는 기간은 과업수행기간에서 제외하여 그 소요기간 만큼 과업수행기간을 연장하여야 한다.

1. 계획수립추진과정

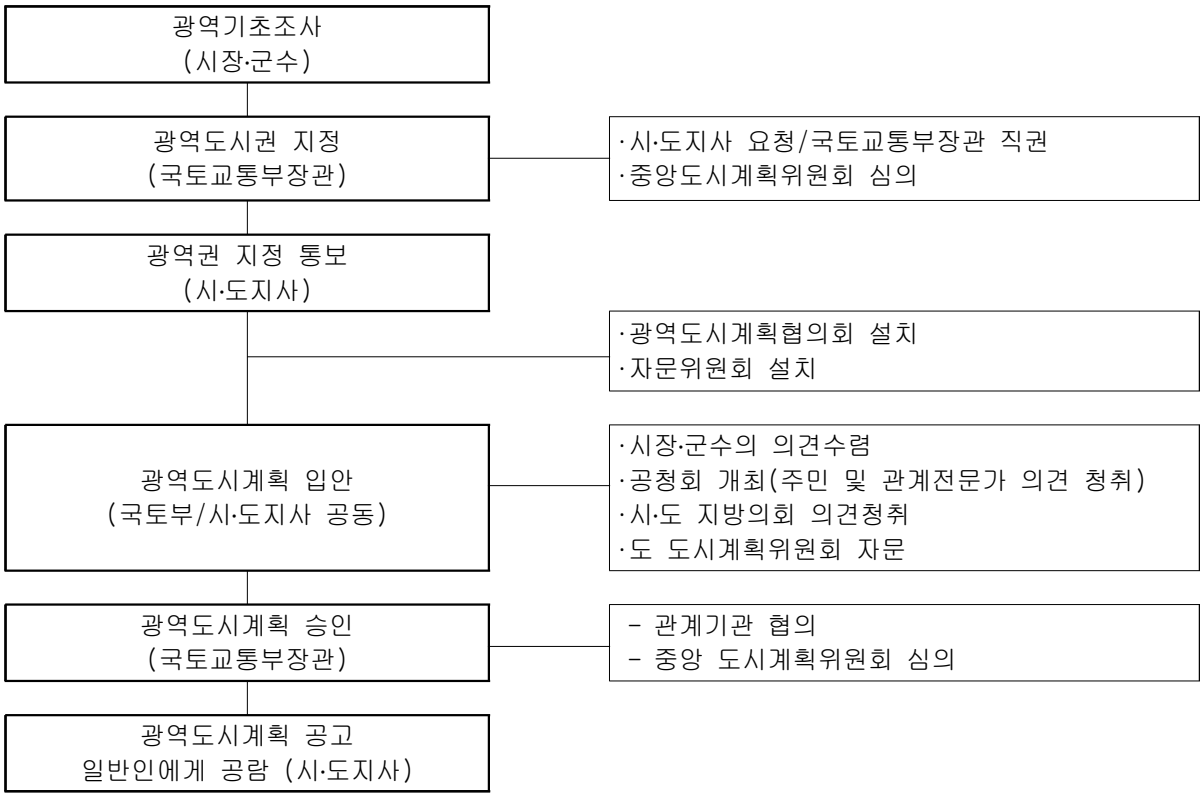

2. 과업수행추진과정

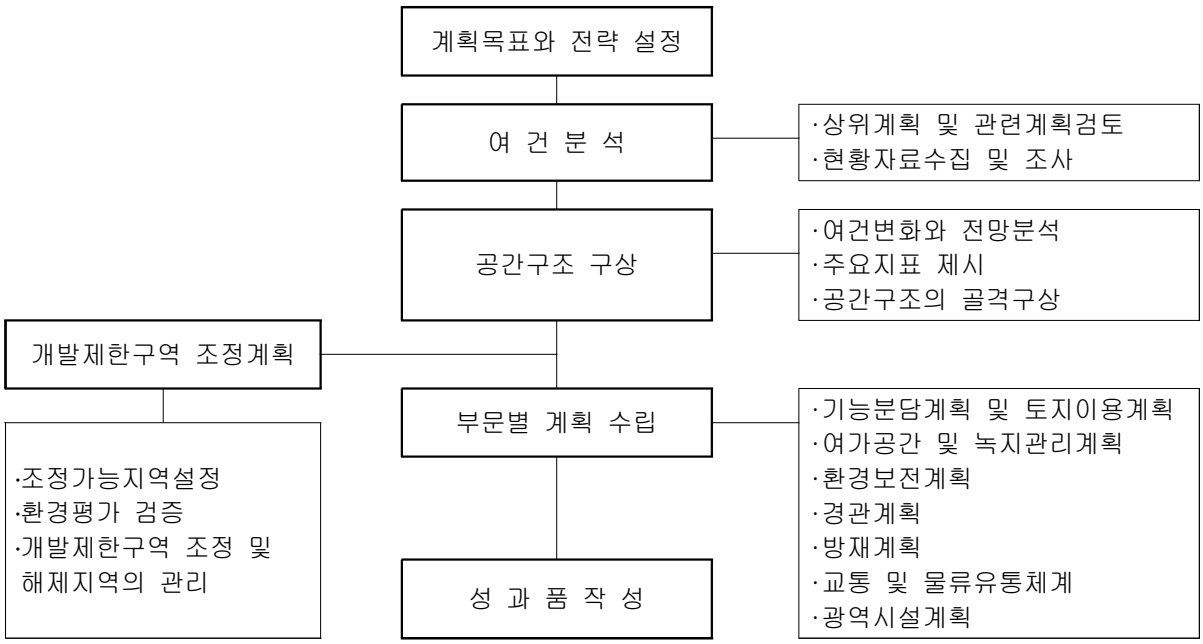

1-4 품 산정의 원단위 산정과 기준

1-4-1 표준품 산정내역

○ 표준품 산정의 기준이 되는 비목은 제1장 총칙에서 제시한 비목을 중심으로 하였으며, 이는 광역도시계획수립에 필요한 사항만을 대상으로 한다.

○ 표준품 산정의 기준이 되는 직접인건비 품의 작업항목별 보할은 업무의 난이도를 감안하여 설정토록 한다.

종 별		내 용	세부항목	단 위	비 고
직접비	직접인건비	1.계획의 목표와 전략	①계획의 목표설정 ②계획의 전략제시 ③상위 및 관련계획 검토	인·일 〃 〃	
		2.광역도시권의 현황 및 특성	①자연환경조사 ②인문환경조사 ③환경여건조사 ④산업현황조사 ⑤광역도시권 특성조사	〃 〃 〃 〃 〃	
		3.공간구조구상	①여건변화와 전망분석 ②주요지표 제시 ③공간구조의 골격구상	〃 〃 〃	
		4.부문별 계획	①기능분담계획 및 토지이용계획 ②여가공간 및 녹지관리계획 ③환경보전계획 ④경관계획 ⑤방재계획 ⑥교통 및 물류유통체계 ⑦광역시설계획 ⑧저탄소 녹색계획 ⑨기후변화 대비계획	〃 〃 〃 〃 〃 〃 〃 〃 〃	
		5.개발제한구역의 조정	-	〃	(필요시)
		6.집행 및 관리계획	①단계별추진계획 ②집행 및 관리계획 ③행·재정계획	〃 〃 〃	
		7.성과품작성	①보고서작성 및 편집 ②관련도서작성	〃 〃	
		8.기술협의	①공청회/주민설명회 ②주민간담회/시민계획단 ③위원회심의 지원 ④관계기관 협의	〃 〃 〃 〃	
	직접경비	여비, 인쇄비, 조감도, 회의준비비, 현장운영비 등		식	제1장 총칙참조
간접비	제 경 비	(직접인건비)×120%		〃	〃
	기 술 료	(직접인건비+제경비) ×25%		〃	〃

1-4-2 산정 기준

1. 계획·기준인구의 설정

○ 기준인구는 전국 시·군의 인구분포를 분석하여 인구 50만인으로 하였으며, 직능별 직접인력 소요원단위는 기 작성된 도시·군기본계획 등의 투입기술자 비율을 감안하여 설정하였다.

○ 계획인구는 광역계획권의 목표인구를 원칙으로 한다.

2. 표준품의 산정방법

○ 표준품의 적용에 있어 기준인구와 계획인구의 차이에 따른 품 산정은 아래의 수정식에 따라 기준인구의 소요작업량을 수정하여 산정한다.

○ 소요작업량 = 기준인구 소요작업량 × 인구보정계수(α)

3. 계획안의 수정과 과업중지에 따른 품 산정방법

○ 계획안이 작성되고 주민공람, 의회보고 등 행정절차과정을 거쳐 계획안이 확정된 후 발주자의 사정에 의하여 계획안이 일부변경 · 재작업이 수행되는 경우에는 그 변경·재작업의 정도에 따라 엔지니어링사업대가의 50～100% 수준에서 비용을 추가 지급하여야 한다.

○ 과업수행 중 발주자의 사정에 따른 과업 중단으로 인해 정부 회계연도가 경과되어 현저한 비용의 차이가 발생하였을 경우에는 엔지니어링사업대가를 당해 신년도의 노임단가를 기준으로 재산정하여야 한다.

1-4-3 단위별 변화수정과 보정

1. 인구의 대소에 대한 작업량 보정계수 산정

○ 광역권 계획인구가 기준인구를 초과하거나 못 미치는 경우의 직접인력 소요작업량의 산정을 위한 보정계수(α)는 다음의 식에 의해 산정한다.

$$\alpha = \left(\frac{\text{계획인구}}{\text{기준인구}}\right)^{0.5} = \left(\frac{A}{50}\right)^{0.5}$$

α = 보정계수
A = 계획인구(만인)

계획단위 인구별 보정계수

계획인구(만인)	보정계수(α)	계획인구(만인)	보정계수(α)
50	1.000	200	2.000
70	1.183	250	2.236
100	1.414	300	2.449
120	1.549	500	3.162
150	1.732	1,000	4.472

주 : 계획인구가 50만인 미만인 경우에는 계획인구 50만인을 기준으로 하여 산정한다.

2. 직접인건비 소요 작업량 산정

○ 계획인구의 대소에 따른 직접인력 소요작업량의 산정방법은 아래와 같이 기준인구의 직능별 직접인력 소요작업량에 계획단위면적의 보정계수(α)를 곱하여 산출한다.

구 분	기준인구 (만인)	총작업량(인·일)					
		기술사	특 급	고 급	중 급	초 급	보조원
광역도시계획	50	100.0α	159.0α	391.0α	740.0α	792.0α	865.0α

1-5 표준단위 업무분류와 원단위

기술업무의 직능별 직접인력 소요작업량(인구50만인 기준)

(단위 : 인 · 일/표준단위)

구 분	업무내용	표준단위	소요인력						비고
			기술사	특 급	고 급	중 급	초 급	보조원	
1.계획의 목표와 전략	①계획의 목표설정	50만인	2.0	3.2	5.9	7.4	7.9	8.7	
	②계획의 전략제시	50만인	2.0	3.2	5.9	7.4	7.9	8.7	
	③상위 및 관련계획 검토	50만인	2.0	3.2	7.8	14.8	15.8	17.3	
	소 계		6.0	9.6	19.6	29.6	31.6	34.7	
2.광역도시권의 현황 및 특성	①자연환경조사	50만인	2.0	3.2	11.7	22.2	23.8	26.0	
	②인문환경조사	50만인	2.0	3.2	11.7	29.6	31.7	34.6	
	③환경여건조사	50만인	2.0	3.2	11.7	29.6	31.7	34.6	
	④산업현황조사	50만인	2.0	3.2	11.7	29.6	31.7	34.6	
	⑤광역도시권 특성조사	50만인	2.0	3.2	11.7	22.2	23.8	26.0	
	소 계		10.0	16.0	58.5	133.2	142.7	155.8	
3.공간구조 구상	①여건변화와 전망분석	50만인	3.0	4.8	7.8	14.8	7.9	8.7	
	②주요지표 제시	50만인	4.0	6.4	11.7	14.8	11.9	13.0	
	③공간구조의 골격구상	50만인	4.0	6.4	11.7	14.8	11.9	13.0	
	소 계		11.0	17.6	31.2	44.4	31.7	34.7	
4.부문별계획	①기능분담계획 및 토지이용계획	50만인	13.0	20.5	50.9	99.9	106.9	116.7	
	②여가공간 및 녹지관리계획	50만인	9.0	14.3	35.2	70.3	75.2	82.1	
	③환경보전계획	50만인	9.0	14.3	35.2	70.3	75.2	82.1	
	④경관계획	50만인	-	-	-	-	-	-	주1
	⑤방재계획	50만인	9.0	14.3	35.2	70.3	75.2	82.1	
	⑥교통 및 물류유통체계	50만인	13.0	20.5	50.9	99.9	106.9	116.7	
	⑦광역시설계획	50만인	9.0	14.3	35.2	70.3	75.2	82.1	
	⑧저탄소 녹색계획	50만인	-	-	-	-	-	-	주2
	⑨기후변화 대비계획	50만인	-	-	-	-	-	-	주2
	소 계		62.0	98.2	242.6	481	514.6	561.8	
5.집행 및 관리계획	①단계별추진계획	50만인	3.0	4.8	9.8	11.1	11.9	13.0	
	②집행 및 관리계획	50만인	3.0	4.8	9.8	11.1	11.9	13.0	
	③행·재정계획	50만인	2.0	3.2	7.8	7.4	7.9	8.7	
	소 계		8.0	12.8	27.4	29.6	31.7	34.7	
6.성과품작성	①보고서작성 및 편집	50만인	2.0	3.2	7.8	14.8	15.9	17.3	
	②관련도서작성	50만인	1.0	1.6	3.9	7.4	23.8	26.0	
	소 계		3.0	4.8	11.7	22.2	39.7	43.3	
총 계			100.0	159.0	391.0	740.0	792.0	865.0	
7.기술 협의	①공청회/주민설명회	1식	2.0	2.0	2.0	4.0	4.0	4.0	
	②주민간담회/시민계획단	1식	2.0	2.0	2.0	4.0	4.0	4.0	
	③위원회심의 지원	1식	2.0	2.0	2.0	4.0	4.0	4.0	주3
	④관계기관 협의	1식	2.0	2.0	2.0	4.0	4.0	4.0	
	소 계		8.0	8.0	8.0	16.0	16.0	16.0	

주 : ①경관계획은 제7장 도시경관의 엔지니어링 산정품을 적용한 별도 엔지니어링 활동업무로 계상한다.

②저탄소, 기후변화, 각종영향성검토, 각종영향평가업무 등은 별도의 엔지니어링활동업무로 계상한다.

③기술협의는 2회 이내 기준이며, 횟수가 늘어날 경우 증가배수에 해당하는 작업품과 비용을 가산한다. (필요항목 선택적 적용)

④각종영향성검토 및 각종영향평가업무는 별도의 엔지니어링활동업무로 계상한다.

1-6 주요업무내용

구 분	업무내용	내 용
1.계획의 목표와 전략	①계획의 목표설정	·계획의 배경 및 개발목표 설정
	②계획의 전략제시	·계획전략 제시
	③상위 및 관련계획 검토	·상위 관련계획과의 상관성 검토
2.광역도시권의 현황 및 특성	①자연환경조사	·수문, 표고, 경사도 등 지형지세조사 ·강수량, 기온, 천기일수, 풍향 등 기상조사 ·기타 토양, 식생, 경관조사
	②인문환경조사	·인구 및 가구조사 ·지목별, 용도별 토지이용 현황조사 ·기반시설 조사
	③환경여건조사	·오염물질 배출량 ·대기내 오염물질, 폐기물 성상 등
	④산업현황조사	·산업체수 조사 ·산업별 종사자 현황 조사 ·산업별 부가가치 생산액 조사 등
	⑤광역도시권 특성조사	·국토공간 및 동북아시아에서의 지리적 위치와 특성 ·국내외 유사 광역도시권과의 비교분석 ·역사적, 문화적, 사회적, 환경적 특성 분석정리 ·잠재력 및 개발제약요인
3.공간구조 구상	①여건변화와 전망분석	·장래 광역 여건 분석 내용 제시 ·미래 비전 및 전략 마련
	②주요지표 제시	·인구 및 가구에 관한 지표 설정 ·토지용도 및 생활환경지표의 설정
	③공간구조의 골격구상	·개발축(성장축), 교통축, 녹지축 설정 ·생활권 설정
4.부문별 계획	①기능분담계획 및 토지이용계획	·광역 토지이용계획 수립
	②여가공간 및 녹지관리계획	·여가공간 및 녹지관리계획 수립
	③환경보전계획	·환경보전 및 관리계획
	④경관계획	·경관유형 구분 및 관리방안
	⑤방재계획	·재해방지계획
	⑥교통 및 물류유통체계	·광역교통계획 및 물류유통시설 관리계획
	⑦광역시설계획	·광역시설계획 ·공급처리시설계획 및 폐기물처리시설계획
	⑧저탄소 녹색계획	·저탄소녹색도시 조성 계획
	⑨기후변화 대비계획	·재해취약성 조사 결과 요약 ·기후 변화에 따른 저감 방안
5.집행 및 관리 계획	①단계별추진계획	·기간별 사업계획
	②집행 및 관리계획	·재원 집행계획 ·연차별 집행계획
	③행·재정계획	·재원조달계획

1-7 표준성과품

성과구분	표준성과도서			비 고
	구 분	규 격	제출부수	
현황도	·토지이용현황도 ·환경현황도 ·광역도시권 현황종합도	1/50,000 1/50,000 1/50,000	1부 1부 1부	
계획도	·광역도시권 기본구상도 ·광역교통계획도 ·여가공간 및 녹지체계구상도	1/50,000 1/50,000 1/50,000	10부 10부 10부	
보고서	·광역도시계획 보고서 ·공청회개최 의견조치 내용 ·현황자료집			발주자와 협의

주 : ①제출부수 및 성과품 종류가 증가할 경우에는 증가배수에 해당하는 작업품과 비용을 가산한다.
②계획보고서 및 기타 관련자료의 규격, 제출부수는 발주자와의 협의에 의하여 비용을 산정한다.

제2절 도시·군기본계획

2-1 정 의

○ 도시·군기본계획은 상위계획인 국토종합계획, 광역도시계획 등의 지침을 수용 발전시켜 도시민의 삶의 질을 향상시키며, 도시가 환경적으로 건전하고 지속 가능하게 발전할 수 있도록 토지이용·교통·환경·안전·산업·정보통신·보건·후생·안보·문화 등에 관한 계획의 수립과 인구, 경제, 사회의 성장과 발전에 따른 미래상을 제시하는 종합계획으로 관할시장 또는 군수가 20년 장기발전계획을 수립하고, 시 · 도지사의 승인을 얻어 확정하며, 당해 도시에 대한 다른 계획과 토지의 개발·정비·보전의 지침이 되는 계획을 말한다.

2-2 자료제공의 전제

○ 당해 계획의 수립에 필요한 모든 관련자료는 원칙적으로 발주자가 제공하는 것으로 하되, 발주자가 보유하지 않는 자료는 엔지니어링사업자가 조사·수집한다.

○ 발주자가 제공하지 못하는 자료의 조사에 있어서는 그 규모·내용에 의거하여 별도의 엔지니어링사업대가를 산정하여 엔지니어링사업자가 수행하며, 당해 관련자료의 기밀성과 광범위한 자료가 요구될 경우는 조사·분석에 필요한 상당기간과 자료수집비용이 전제되어야 한다.

2-3 업무범위와 추진과정

2-3-1 업무범위

○ 환경적으로 건전하고 지속가능한 도시권의 발전을 위해 “도시·군기본계획 수립지침”에서 제시하고 있는 부문별 내용이 포함되는 계획을 수립하여야 한다. 다만, 특정부문 중심으로 계획을 수립하는 경우에는 해당부문에 대하여 중점적으로 계획을 수립할 수 있다.

○ 도시·군기본계획권내에 개발제한구역이 포함되어 있을 경우에는 개발제한구역 조정계획과 개발제한구역에 대한 환경평가 검증을 업무범위에 포함시키도록 한다.

2-3-2 추진과정

○ 타부처(관계기관)와의 협의나 전문가 자문 등에 소요되는 기간은 과업수행기간에서 제외하여 그 소요기간 만큼 과업수행기간을 연장하여야 한다.

1. 계획수립추진과정

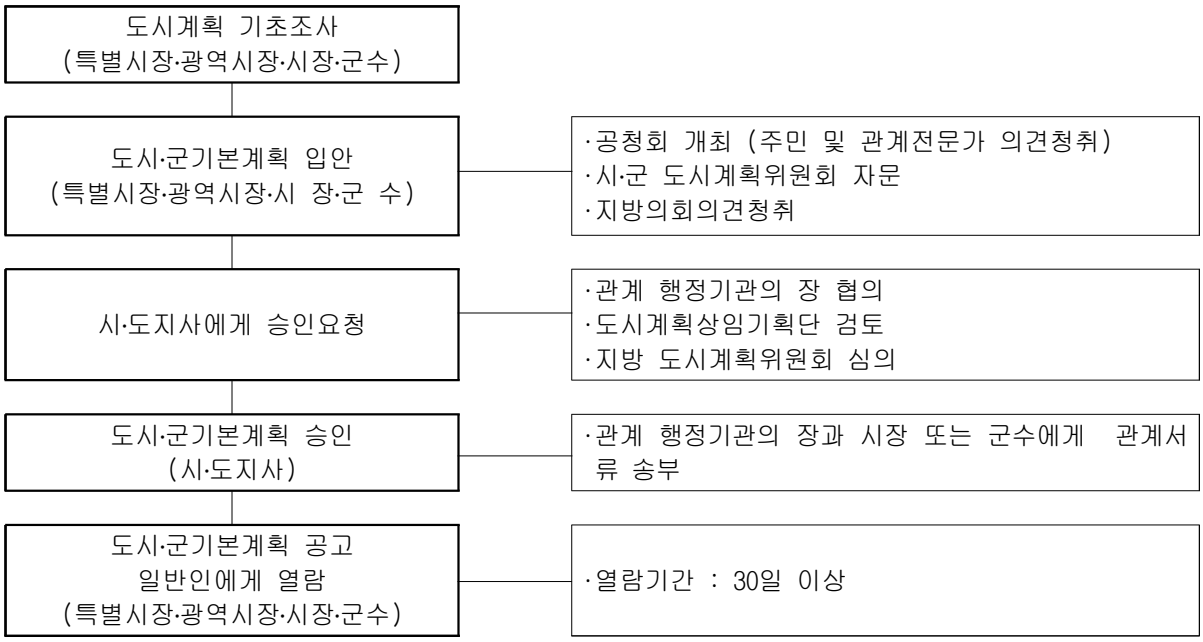

2. 과업수행추진과정

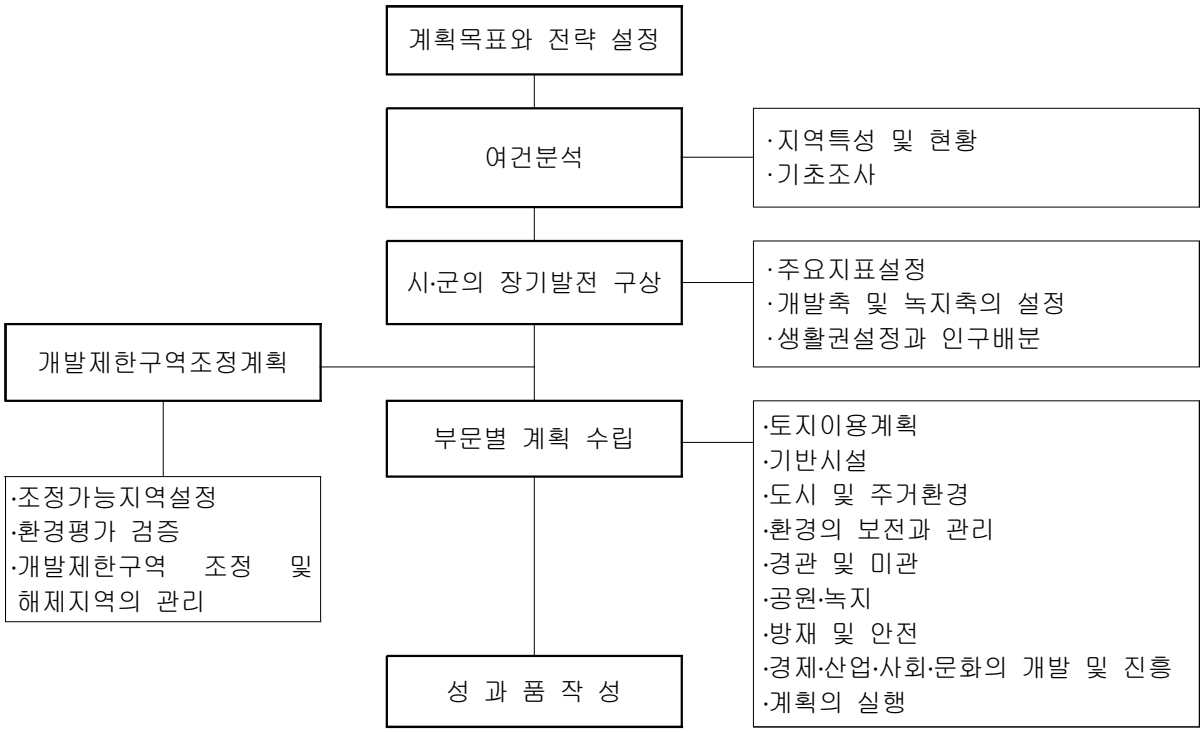

2-4 품 산정의 원단위 산정과 기준

2-4-1 표준품내역

○ 표준품 산정의 기준이 되는 비목은 제1장 총칙에서 제시한 비목을 중심으로 하였으며, 이는 도시·군기본계획수립에 필요한 사항만을 대상으로 한다.

○ 표준품 산정의 기준이 되는 직접인건비 품의 작업항목별 보할은 업무의 난이도를 감안하여 설정토록 한다.

종 별		내 용	세부항목	단 위	비 고
직접비	직접인건비	1.조사분석	①기초조사 ②지역특성 및 현황	인·일 〃	
		2.기본구상	①계획의 목표와 지표설정 ②공간구조의 설정	〃 〃	
		3.부문별 계획	①토지이용계획 ②기반시설 ③도심 및 주거환경 ④환경의 보전과 관리 ⑤경관 및 미관 ⑥공원·녹지 ⑦방재 및 안전 ⑧경제·산업·사회·문화의 개발 및 진흥 ⑨저탄소 녹색계획 ⑩기후변화 대비계획 ⑪계획의 실행	〃 〃 〃 〃 〃 〃 〃 〃 〃 〃 〃	
		4.성과품 작성	①보고서작성 및 편집 ②관련도서 작성	〃 〃	
		5.기술협의	①공청회/주민설명회 ②주민간담회/시민계획단 ③위원회심의 지원 ④관계기관 협의	〃 〃 〃 〃	
	직접경비	여비, 인쇄비, 조감도, 회의준비비, 현장운영비 등		식	제1장 총칙참조
간접비	제경비	(직접인건비)×120%		〃	〃
	기술료	(직접인건비+제경비) ×25%		〃	〃

2-4-2 산정 기준

1. 계획·기준인구의 설정

○ 기준인구는 전국의 시·군 인구분포를 분석하여 인구 10만인으로 하였으며, 직능별 직접인력 소요원단위는 기 작성된 시·군 도시·군기본계획 등의 투입기술자 비율을 감안하여 설정하였다.

○ 계획인구는 당해 도시권의 목표인구를 원칙으로 한다.

2. 표준품의 산정방법

○ 표준품의 적용에 있어 기준인구와 계획인구의 차이에 따른 품 산정은 아래의 수정식에 따라 기준인구의 소요작업량을 수정하여 산정한다.

○ 소요작업량 = 기준인구 소요작업량 × 인구보정계수(α)

3. 계획안의 수정과 과업중지에 따른 품 산정방법

○ 계획안이 작성되고 공청회, 의회보고 등 행정절차과정을 거쳐 계획안이 확정된 후 발주자의 사정에 의하여 계획안이 일부변경 · 재작업이 수행되는 경우에는 그 변경·재작업의 정도에 따라 엔지니어링사업대가의 50～100% 수준에서 비용을 추가 지급하여야 한다.

○ 과업수행 중 발주자의 사정에 따른 과업 중단으로 인해 정부 회계연도가 경과되어 현저한 비용의 차이가 발생하였을 경우에는 엔지니어링사업대가를 당해 신년도의 노임단가를 기준으로 재산정하여야 한다.

2-4-3 단위별 변화수정과 보정

1. 인구의 대소에 대한 작업량 보정계수 산정

○ 도시의 계획인구가 기준인구를 초과하거나 못 미치는 경우의 직접인력 소요작업량의 산정을 위한 보정계수(α)는 다음의 식에 의해 산정한다.

$$\alpha = \left(\frac{\text{계획인구}}{\text{기준인구}}\right)^{0.5} = \left(\frac{A}{10}\right)^{0.5}$$

α = 보정계수
A = 계획인구(만인)

계획단위 인구별 보정계수

계획인구(만인)	보정계수(α)	계획인구(만인)	보정계수(α)
10	1.000	100	3.162
20	1.414	150	3.873
30	1.732	200	4.472
50	2.236	400	6.325
70	2.646	500	7.071

주 : 계획인구가 10만인 미만인 경우에는 계획인구 10만인을 기준으로 하여 산정한다.

2. 직접인건비 소요 작업량 산정

○ 계획인구의 대소에 따른 직접인력 소요작업량의 산정방법은 아래와 같이 기준인구의 직능별 직접인력 소요작업량에 계획단위면적의 보정계수(α)를 곱하여 산출한다.

구 분	기준인구 (만인)	총작업량(인·일)					
		기술사	특 급	고 급	중 급	초 급	보조원
도시·군 기본계획	10	57.4α	91.2α	223.5α	423.8α	460.5α	503.1α

2-5 표준단위 업무분류와 원단위

기술업무의 직능별 직접인력 소요작업량(인구10만인 기준)

(단위 : 인 · 일/표준단위)

구 분	업무내용	표준단위	소요인력						비고
			기술사	특 급	고 급	중 급	초 급	보조원	
1.조사분석	①기초조사	10만인	-	-	-	-	-	-	주1
	②지역특성 및 현황	10만인	8.2	12.9	31.9	55.9	59.7	82.3	
	소 계		8.2	12.9	31.9	55.9	59.7	82.3	
2.기본구상	①계획의 목표와 지표설정	10만인	5.1	8.0	17.5	29.0	22.2	24.2	
	②공간구조의 설정	10만인	13.1	20.9	47.0	80.7	86.4	94.4	
	소 계		18.2	28.9	64.5	109.7	108.6	118.6	
3.부문별계획	①토지이용계획	10만인	3.0	4.9	12.0	24.8	26.6	26.6	
	②기반시설	10만인	6.9	11.1	29.5	60.0	64.2	62.9	
	③도심 및 주거환경	10만인	3.3	5.3	13.1	28.7	31.0	31.9	
	④환경의 보전과 관리	10만인	1.7	2.7	7.1	14.6	15.5	17.6	
	⑤경관 및 미관	10만인	1.7	2.7	7.1	14.5	15.5	17.5	
	⑥공원·녹지	10만인	1.7	2.7	7.1	14.6	15.5	17.6	
	⑦방재 및 안전	10만인	2.3	3.6	9.9	18.7	22.1	21.8	
	⑧경제·산업·사회·문화의 개발 및 진흥	10만인	4.6	7.2	18.7	39.4	40.0	43.6	
	⑨저탄소 녹색계획	10만인	-	-	-	-	-	-	주2
	⑩기후변화 대비계획	10만인	-	-	-	-	-	-	주2
	⑪계획의 실행	10만인	2.8	4.4	10.9	20.7	22.1	19.4	
	소 계		28.0	44.6	115.4	236.0	252.5	258.9	
4.성과품작성	①보고서작성 및 편집	10만인	2.0	3.2	7.8	14.8	15.9	17.3	
	②관련도서 작성	10만인	1.0	1.6	3.9	7.4	23.8	26.0	
	소 계		3.0	4.8	11.7	22.2	39.7	43.3	
총 계			57.4	91.2	223.5	423.8	460.5	503.1	
5.기술협의	①공청회/주민설명회	1식	2.0	2.0	2.0	4.0	4.0	4.0	주3
	②주민간담회/시민계획단	1식	2.0	2.0	2.0	4.0	4.0	4.0	
	③위원회심의 지원	1식	2.0	2.0	2.0	4.0	4.0	4.0	
	④관계기관 협의	1식	2.0	2.0	2.0	4.0	4.0	4.0	
	소 계		8.0	8.0	8.0	16.0	16.0	16.0	

주 : ①기초자료는 "2-2 자료제공의 전제"에 의거 발주자가 제공하여야 하며, 제공하지 못하는 자료에 대하여는 제8절 도시계획 기초조사 산정 품을 참조하여 별도 산정한다.

②저탄소, 기후변화, 각종영향성검토, 각종영향평가업무 등은 별도의 엔지니어링활동업무로 계상한다.

③기술협의는 2회 이내 기준이며, 횟수가 늘어날 경우 증가배수에 해당하는 작업품과 비용을 가산한다. (필요항목 선택적 적용)

④도시·군기본계획 및 도시・군관리계획과 병행하여 별도로 작성되는 도시(지역)교통계획(수립보고서)는 제4절 도시(지역)교통계획을, 경관계획(보고서)은 제7장 도시경관의 엔지니어링 산정품을 적용한 별도 엔지니어링 활동업무로 계상한다.

⑤농지(산지)전용협의 등을 수반하는 업무가 있을 경우에는 별도 작업비를 계상한다.

⑥각종영향성검토 및 각종영향평가업무는 별도의 엔지니어링활동업무로 계상한다.

2-6 주요업무내용

구 분	업무내용	내 용
1.조사분석	①기초조사	·도시·군기본계획 입안시 해당지역 및 주변의 특성을 파악하기 위한 기초자료의 축척 및 분석 ·도시·군기본계획수립 지침에 따라 실시
	②지역특성 및 현황	·역사적, 문화적 특성 ·개발연혁·인구·경제·자연환경·사회개발 현황 ·시·군세력권 분석 - 경제권, 사회권, 환경권 등 ·상위계획분석
2.기본구상	①계획의 목표와 지표설정	·시·군의 미래상 전망 ·지표 - 인구, 경제, 환경지표 등
	②공간구조의 설정	·2개안 이상의 기본골격안 구상 ·생활권설정 및 인구배분계획
3.부문별 계획	①토지이용계획	·토지이용수요분석 및 장래토지이용 예측 ·용도별 수요량 산출 - 주거·상업·공업용지 ·용도구분 및 관리 - 시가화·시가화예정·보전용지 ·관리지역의 세분 연계 ·개발제한구역 해제지역의 관리방안
	②기반시설	·교통체계 - 교통량추정 및 수단별·지역별 배분계획, 광역·도시교통체계구상, 주요 교통시설로의 접근성 제고 ·물류계획 - 시설의 체계적 확충 및 정비 ·정보·통신계획 - 정보통신망시설확충 및 연계계획 ·유비쿼터스계획 ·기타 기반시설계획
	③도심 및 주거환경	·도시재생 - 기반시설, 대중교통 및 보행, 역사문화자원, 거주성등 고려 ·도시 및 시가지 정비 - 재개발·재건축 및 역세권개발, 신구시가지간 균형개발, 취락정비 등 ·주거환경계획 - 주택정책의 목표와 전략제시, 주거환경수준의 기준마련, 주거유형별 배분계획
	④환경의 보전과 관리	·환경친화적 개발의 유도 ·대기환경 및 수환경의 보전 ·상·하수도, 폐기물, 에너지 공급계획
	⑤경관 및 미관	·도시경관관리와 조성계획지침 제시 ·경관관리대상지역 설정 및 관리전략 제시 ·도시경관계획 수립 (필요시 별도)
	⑥공원·녹지	·공원녹지체계 형성의 기본방향 설정 및 제시 ·수공간 이용성 검토 ·공원녹지시설 설치계획 수립
	⑦방재 및 안전	·기후변화, 고령화, 다문화, 정보화 등 도시환경의 여건변화로 인한 재해범죄취약성에 대한 대응전략 마련 ·재해방지 및 방재계획 수립 ·기반시설 및 토지이용체계에 능동적 피해 극소화 계획 ·재해 빈발지역에 예방대책 제시 ·방재시설물의 설치기준, 관리체계 등 수립

구 분	업무내용	내 용
3.부문별 계획 (계속)	⑧경제·산업·사회·문화의 개발 및 진흥	·경제·산업개발계획 -농림수산업·광공업·사회간접자본 및 서비스업 발전계획, 특화산업 및 첨단산업의 발전방향 제시 ·역사·사회·문화개발계획 -의료보건·사회복지·교육·문화체육 개발계획
	⑨저탄소 녹색계획	·저탄소 녹색성장 도시공간 조성방안 수립
	⑩기후변화 대비계획	·폭우, 폭설, 폭염, 가뭄, 해수면상승 조사
	⑪계획의 실행	·재정확충 및 재원조달계획 ·단계별 추진전략 ·주요사업, 장기대규모사업의 사업계획

2-7 표준성과품

성과구분	표준성과도서			비 고
	구 분	규 격	제출부수	
현황도	·지형(표고)현황도 ·토지이용현황도 ·주요시설현황도 ·인구밀도 분포현황도	1/25,000 1/25,000 1/25,000 1/25,000	1부 1부 1부 1부	
계획도	·도시기본구상도 ·공원·녹지체계구상도 ·교통계획도	1/25,000～1/50,000 1/25,000～1/50,000 1/25,000～1/50,000	2부 2부 2부	
보고서	·도시·군기본계획 보고서 ·공청회개최 의견조치내용 ·도시·군기본계획수립에 이용된 자료			발주자와 협의

주 : ①제출부수 및 성과품 종류가 증가할 경우에는 증가배수에 해당하는 작업품과 비용을 가산한다.
②계획보고서 및 기타 관련자료의 규격 및 제출부수는 발주자와의 협의에 의하여 비용을 산정한다.

제3절 도시·군관리계획

3-1 정 의

○ 도시·군관리계획은 광역도시계획 및 도시·군기본계획에서 제시된 시·군의 장기적인 발전방향을 공간에 구체화하고 실현시키는 중기계획으로 토지이용·교통·환경·경관·안전·산업·정보통신·보건·복지·안보·문화 등에 관하여 용도지역·용도지구·용도구역에 관한 계획, 기반시설에 관한 계획, 도시개발사업 또는 정비사업에 관한 계획, 지구단위계획 중 1가지 이상이 포함된 계획이며, 이를 일괄된 체계로 종합화하여 단계적으로 집행할 수 있도록 물적으로 표현하는 계획이다.

3-2 자료제공의 전제

○ 당해 계획의 수립에 필요한 모든 관련자료는 원칙적으로 발주자가 제공하는 것으로 하되, 발주자가 보유하지 않는 자료는 엔지니어링사업자가 조사·수집한다.

○ 발주자가 제공하지 못하는 자료의 조사(교통량조사, 건물조사, 수목 및 산림조사, 도시시설물조사 등)에 있어서는 그 규모·내용에 의거하여 별도의 엔지니어링사업대가를 산정하여 엔지니어링사업자가 수행하며, 당해 관련자료의 기밀성과 광범위한 자료가 요구되는 경우 조사·분석에 필요한 상당기간과 자료수집비용이 전제되어야 한다.

3-3 업무범위와 추진과정

3-3-1 업무범위

○ 도시·군관리계획은 당해 도시의 장래 목표년도에 적정규모의 도시개발지표 달성을 위하여 다음의 도시계획을 그 도시의 특성에 맞게 수립한다.

- 용도지역·용도지구의 지정 또는 변경에 관한 계획
- 개발제한구역·시가화조정구역·수산자원보호구역·도시자연공원구역의 지정 또는 변경에 관한 계획
- 기반시설의 설치·정비·개량에 관한 계획
- 도시개발법에 의한 도시개발사업
- 도시 및 주거환경정비법에 의한 정비사업에 관한 계획
- 지구단위계획구역의 지정 또는 변경에 관한 계획과 지구단위계획

○ 일단으로 구획되는 종합운동장, 유원지, 유통업무설비 등에 대하여는 세부시설계획이 수반되어야 하므로 별도 엔지니어링활동을 수행한다.

○ 장기 미집행시설에 대한 단계별 집행계획에 대하여는 제6절 단계별집행계획의 엔지니어링산정품을 적용한다.

3-3-2 추진과정

○ 타부처(관계기관)와의 협의나 전문가 자문 등에 소요되는 기간은 과업수행기간에서 제외하여 그 소요기간 만큼 과업수행기간을 연장하여야 한다.

1. 계획수립추진과정

2. 과업수행추진과정

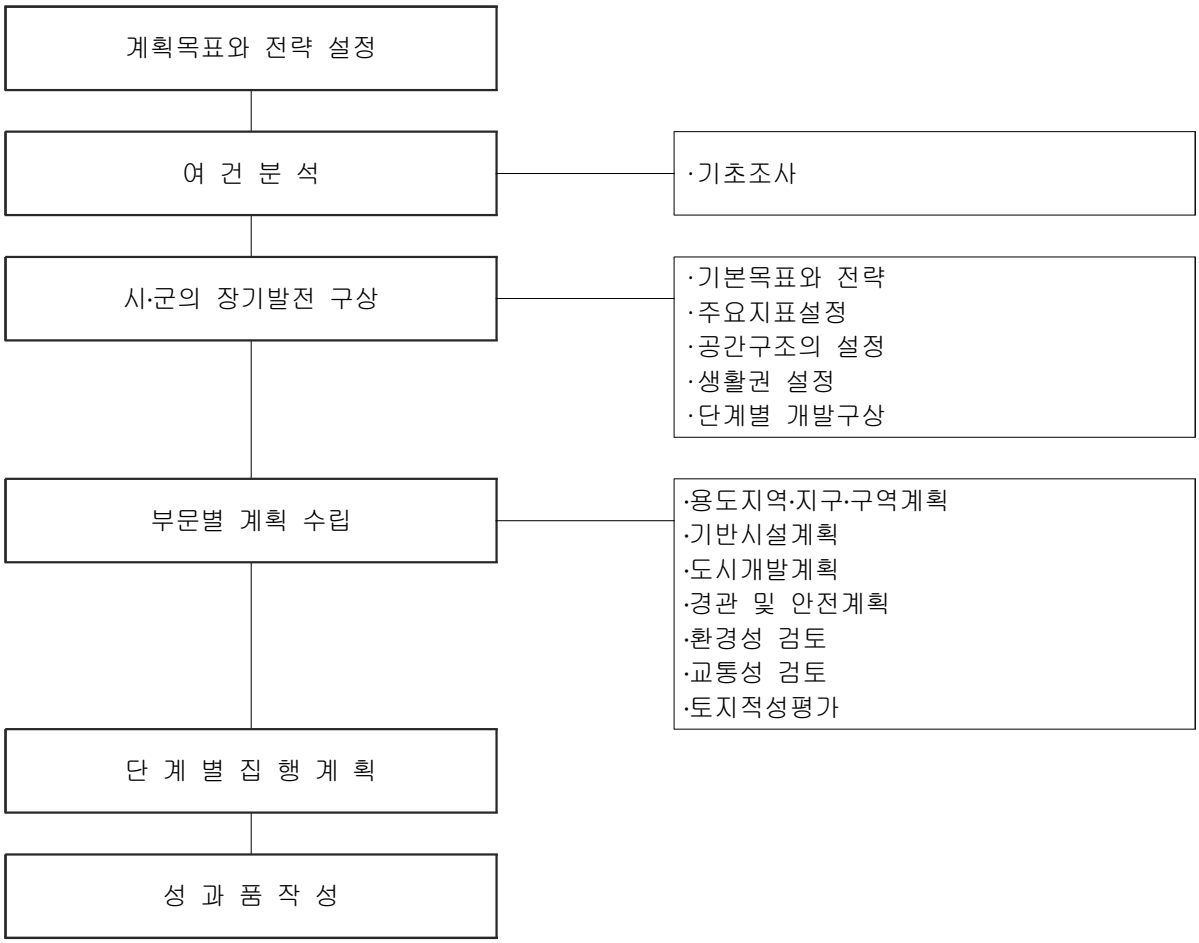
계획목표와 전략 설정
여 건 분 석
·기초조사
시·군의 장기발전 구상
·기본목표와 전략
·주요지표설정
·공간구조의 설정
·생활권 설정
·단계별 개발구상
부문별 계획 수립
·용도지역·지구·구역계획
·기반시설계획
·도시개발계획
·경관 및 안전계획
·환경성 검토
·교통성 검토
·토지적성평가
단 계 별 집 행 계 획
성 과 품 작 성

3-4 품 산정의 원단위 산정과 기준

3-4-1 표준품 산정내역

○ 표준품 산정의 기준이 되는 비목은 제1장 총칙에서 제시한 비목을 중심으로 하였으며, 이는 도시·군관리계획수립에 필요한 사항만을 대상으로 한다.

○ 표준품 산정의 기준이 되는 직접인건비 품의 작업항목별 보할은 항목별 업무의 난이도를 감안하여 설정토록 한다.

1. 도시·군관리계획(재정비)

종 별		내 용	세부항목	단 위	비 고
직접비	직접인건비	1.조사분석	①기초조사	인·일	
		2.기본구상	①계획의 배경 ②도시개발의 장기구상	〃 〃	
		3.부문별 계획	①용도지역·지구·구역계획 ②기반시설계획 ③도시개발계획 ④경관계획 (별도) ⑤단계별 집행계획 (별도) ⑥환경성검토 (별도) ⑦교통성검토 (별도) ⑧토지적성평가 (별도) ⑨재해취약성분석 (별도)	〃 〃 〃 〃 〃 〃 〃 〃 〃	
		4.성과품 작성	①보고서작성 및 편집 ②관련도서작성	〃 〃	
		5.기술협의	①공청회/주민설명회 ②주민간담회/시민계획단 ③위원회심의 지원 ④관계기관 협의	〃 〃 〃 〃	
	직접경비	여비, 인쇄비, 조감도, 회의준비비, 현장운영비 등		식	제1장 총칙참조
간접비	제경비	(직접인건비)×120%		〃	〃
	기술료	(직접인건비+제경비) ×25%		〃	〃

2. 도시·군관리계획(변경)결정 (부분·단위)

종 별		내 용		단 위	비 고
직접비	직접인건비	1.계획검토	①관련법규 및 계획 검토 ②주변지역과의 상관성검토	인·일 〃	
		2.도시·군계획시설결정변경도서작성	①도시·군계획시설(변경)결정 조서 ②도시·군계획시설(변경)결정 사유서 및 개발(사업)계획서 ③각종 영향 검토서 분석 ④공고에 따른 의견내용 및 조치결과 작성 ⑤도시·군계획시설(변경)결정도 및 지형고시도면 작성 ⑥시설배치 및 토지이용계획 ⑦지적도 및 토지조서, 권리조서 작성 ⑧농지관련 서류작성 ⑨산지.초지관련 서류작성	〃 〃 〃 〃 〃 〃 〃 〃	
		3.성과품 작성	①보고서작성 및 편집 ②관련도서작성	〃 〃	
		4.기술협의	①공청회/주민설명회 ②주민간담회/시민계획단 ③위원회심의 지원 ④관계기관 협의	〃 〃 〃 〃	
	직접경비	여비, 인쇄비, 조감도, 회의준비비, 현장운영비 등		식	제1장 총칙참조
간접비	제경비	(직접인건비)×120%		〃	〃
	기술료	(직접인건비+제경비) ×25%		〃	〃

3-4-2 산정 기준

1. 계획·기준인구(면적)의 설정

○ 기준인구는 전국 도시의 인구분포를 분석하여 인구 5만인으로 하였으며, 직능별 직접인력 소요원단위는 기 작성된 시·군 도시·군관리계획 등의 투입기술자 비율을 감안하여 설정하였다.

○ 계획인구는 당해 도시권의 목표인구를 원칙으로 한다.

○ 도시·군계획시설의 계획면적(거리)는 해당 시설의 종류에 따라 면적(面的)시설 또는 선적(線的)시설로 구분하고, 구분에 따라 규모를 산정하며 기준면적은 1만㎡(1.0km)를 원칙으로 한다.

2. 표준품의 산정방법

○ 표준품의 적용에 있어 기준인구와 계획인구의 차이에 따른 품 산정은 아래의 수정식에 따라 기준인구·면적의 소요작업량을 수정하여 산정한다.

○ 소요작업량 = 기준인구·면적 소요작업량 × 인구·면적보정계수(α)

3. 계획안의 수정과 과업중지에 따른 품 산정방법

○ 계획안이 작성되고 주민공람, 의회보고 등 행정절차과정을 거쳐 계획안이 확정된 후 발주자의 사정에 의하여 계획안이 일부변경 · 재작업이 수행되는 경우에는 그 변경·재작업의 정도에 따라 엔지니어링사업대가의 50～100% 수준에서 비용을 추가 지급하여야 한다.

○ 과업수행 중 발주자의 사정에 따른 과업 중단으로 인해 정부 회계연도가 경과되어 현저한 비용의 차이가 발생하였을 경우에는 엔지니어링사업대가를 당해 신년도의 노임단가를 기준으로 재산정하여야 한다.

3-4-3 단위별 변화수정과 보정

1. 인구 및 면적의 대소에 대한 작업량 보정계수 산정

1) 도시·군관리계획(재정비)

○ 도시의 계획인구가 기준인구를 초과하거나 못 미치는 경우의 직접인력 소요작업량의 산정을 위한 보정계수(α)는 다음의 식에 의해 산정한다.

$$\alpha = \left(\frac{\text{계획인구}}{\text{기준인구}}\right)^{0.6} = \left(\frac{A}{5}\right)^{0.6}$$

α = 보정계수
A = 계획인구(만인)

계획단위 인구별 보정계수

계획인구(만인)	보정계수 (α)	계획인구(만인)	보정계수 (α)
1	0.381	30	2.930
3	0.736	50	3.981
5	1.000	100	6.034
10	1.516	150	7.696
20	2.297	200	9.146

주 : 계획인구가 1만인 미만인 경우에는 계획인구 1만인을 기준으로 하여 산정한다.

2) 도시·군관리계획(변경)결정(부분·단위)

○ 도시·군관리계획 면적(길이)이 기준을 초과하거나 이에 못 미치는 경우의 직접인력 소요작업량의 산정을 위한 각 작업내용별 면적보정계수(α)는 다음과 같이 산정한다.

$$\alpha = [\frac{\text{계획면적(거리)}}{\text{기준면적(거리)}}]^{0.6} = (\frac{A}{1})^{0.6}$$

α = 보정계수
A = 계획면적,거리(만㎡, ㎞)

계획단위 면적별 보정계수

계획면적(만㎡)·거리(㎞)	보정계수(α)	계획면적(만㎡)·거리(㎞)	보정계수(α)
0.5	0.660	20.0	6.034
1.0	1.000	40.0	9.146
2.0	1.516	60.0	11.665
5.0	2.627	70.0	12.796
10.0	3.981	100.0	15.849

주 : ①계획면적이 0.5만㎡(0.5㎞)미만인 경우에는 계획면적 0.5만㎡(0.5㎞)를 기준으로 하여 산정한다.
②평균폭이 25m 이상의 선적시설은 면적을 기준으로 산정한다.

2. 직접인건비 소요 작업량 산정

○ 계획인구의 대소에 따른 직접인력 소요작업량의 산정방법은 아래와 같이 기준인구의 직능별 직접인력 소요작업량에 계획단위면적의 보정계수(α)를 곱하여 산출한다.

구 분	기 준	총작업량(인·일)					
		기술사	특 급	고 급	중 급	초 급	보조원
도시·군관리계획 (재정비)	5만인	54.3α	86.5α	270.6α	363.2α	383.1α	405.4α
도시·군관리계획 (변경)결정	1만㎡ (1.0㎞)	3.6α	8.7α	23.6α	31.5α	61.0α	73.7α

3-5 표준단위 업무분류와 원단위

도시·군관리계획(재정비) 기술업무의 직능별 직접인력 소요작업량(인구 5만인 기준)

(단위 : 인 · 일/표준단위)

구 분	업무내용	표준단위	소요인력						비고
			기술사	특 급	고 급	중 급	초 급	보조원	
1.조사분석	①기초조사		-	-	-	-	-	-	주1
2.기본구상	①계획의 배경	5만인	2.7	4.3	13.1	20.1	20.2	21.3	주2
	②시·군의 장기발전구상	5만인	5.4	8.5	26.2	40.1	20.2	21.3	
	소 계		8.1	12.8	39.3	60.2	40.4	42.6	
3.부문별계획	①용도지역·지구·구역계획	5만인	10.8	17.2	52.4	60.1	60.6	63.9	
	②기반시설계획	5만인	29.7	47.4	154.1	200.6	222.2	234.3	
	③도시개발계획	5만인	2.7	4.3	13.1	20.1	20.2	21.3	
	④경관계획	5만인	-	-	-	-	-	-	주3
	⑤단계별 집행계획	5만인	-	-	-	-	-	-	주4
	⑥환경성 검토	5만인	-	-	-	-	-	-	주5
	⑦교통성 검토	5만인	-	-	-	-	-	-	주6
	⑧토지적성평가	5만인	-	-	-	-	-	-	주7
	⑨재해취약성분석	5만인	-	-	-	-	-	-	주8
	소 계		43.2	68.9	219.6	280.8	303.0	319.5	
4.성과품작성	①보고서작성 및 편집	5만인	2.0	3.2	7.8	14.8	15.9	17.3	
	②관련도서작성	5만인	1.0	1.6	3.9	7.4	23.8	26.0	
	소 계		3.0	4.8	11.7	22.2	39.7	43.3	
총 계			54.3	86.5	270.6	363.2	383.1	405.4	
5.기술협의	①공청회/주민설명회	1식	2.0	2.0	2.0	4.0	4.0	4.0	주9
	②주민간담회/시민계획단	1식	2.0	2.0	2.0	4.0	4.0	4.0	
	③위원회심의 지원	1식	2.0	2.0	2.0	4.0	4.0	4.0	
	④관계기관 협의	1식	2.0	2.0	2.0	4.0	4.0	4.0	
	소 계		8.0	8.0	8.0	16.0	16.0	16.0	

주 : ①기초자료는 "3-2 자료제공의 전제"에 의거 발주자가 제공하여야 하며, 제공하지 못하는 자료에 대하여는 제8절의 도시계획 기초조사의 품을 참조하여 별도 산정한다.

②도시·군기본계획과 도시·군관리계획을 단일 건으로 종합하여 발주할 경우 "2-①.계획의 배경과 2-②.시군의 장기발전구상" 항목에 대하여는 기술자의 투입인력을 60% 감할 수 있다.

③경관계획은 제7장 도시경관의 엔지니어링품을 별도 적용한다

④장기 미집행시설에 대한 단계별집행계획은 제6절 단계별집행계획의 엔지니어링품을 별도 적용한다.

⑤각종영향성검토 및 각종영향평가업무는 별도의 엔지니어링활동업무로 계상한다.

⑥도시·군기본계획 및 도시·군관리계획과 병행하여 별도로 작성되는 도시(지역)교통계획(수립보고서)은 제4절 도시(지역)교통계획의 별도의 엔지니어링활동업무로 계상한다.

⑦도시·군관리계획 및 도시·군계획시설 변경 결정시 별도로 작성하는 토지적성평가는 제8장제2절 토지적성평가의 엔지니어링품을 적용한다.

⑧재해취약성분석은 제8장제3절 재해취약성분석의 엔지니어링품을 별도 적용한다

⑨기술협의는 2회 이내 기준이며, 횟수가 늘어날 경우 증가배수에 해당하는 작업품과 비용을 가산한다. (필요항목 선택적 적용)

도시·군관리계획(변경)결정(부분·단위) 기술업무의 직능별 직접인력 소요작업량(1만㎡,1㎞기준)

(단위 : 인 · 일/표준단위)

구 분	업무내용	표준 단위	소요인력						비고
			기술사	특 급	고 급	중 급	초 급	보조원	
1.계획검토	①관련법규 및 계획 검토	1만㎡외	0.4	0.6	1.2	1.8	3.0	3.5	
	②주변지역과의 상관성검토	1만㎡외	0.2	0.4	0.8	1.2	2.0	2.5	
	소 계		0.6	1.0	2.0	3.0	5.0	6.0	
2.도시·군계획 시설결정	①도시·군계획시설(변경)결정 조서	1만㎡외	0.4	1.0	2.4	3.0	6.0	8.5	
	②도시·군계획시설(변경)결정사 유서 및 개발(사업)계획서	1만㎡외	0.6	1.0	6.0	7.0	15.0	12.0	주1
	③각종 영향 검토서	1만㎡외	0.4	1.0	2.4	3.0	6.0	8.5	
	④공고에 따른 의견내용 및 조치결과 작성	1만㎡외	0.6	0.6	1.2	2.0	3.0	4.5	
	⑤도시·군계획시설(변경)결정도	1만㎡외	-	1.0	2.4	3.0	6.0	8.5	
	⑥시설배치 및 토지이용계획	1만㎡외	0.4	1.0	2.4	3.0	6.0	8.5	
	⑦지적도 및 토지조서, 권리조서 작성	1만㎡외	-	1.2	2.4	3.0	6.0	8.5	
	⑧농지관련 서류작성	1만㎡외	-	-	-	-	-	-	주2
	⑨산지.초지관련 서류작성	1만㎡외	-	-	-	-	-	-	주2
	소 계		2.4	6.8	19.2	24.0	48.0	59.0	
3.성과품작성	①보고서작성 및 편집	1만㎡외	0.4	0.6	1.6	3.0	3.2	3.5	
	②관련도서작성	1만㎡외	0.2	0.3	0.8	1.5	4.8	5.2	
	소 계		0.6	0.9	2.4	4.5	8.0	8.7	
총 계			3.6	8.7	23.6	31.5	61.0	73.7	
4.기술협의	①공청회/주민설명회	1식	2.0	2.0	2.0	4.0	4.0	4.0	주3
	②주민간담회/시민계획단	1식	2.0	2.0	2.0	4.0	4.0	4.0	
	③위원회심의 지원	1식	2.0	2.0	2.0	4.0	4.0	4.0	
	④관계기관 협의	1식	2.0	2.0	2.0	4.0	4.0	4.0	
	소 계		8.0	8.0	8.0	16.0	16.0	16.0	

주 : ①변경(결정)도서작성에 필요한 개발(사업)계획 내용은 발주자측이 제공하며, 제공하지 못할 경우 별도의 엔지니어링업무로 산정한다.

②농지·산지전용협의, 각종영향성검토 및 각종영향평가업무는 별도의 엔지니어링활동업무로 계상한다. 토지적성평가 등은 별도 관련품을 적용한다.

③기술협의는 2회 이내 기준이며, 횟수가 늘어날 경우 증가배수에 해당하는 작업품과 비용을 가산한다. (필요항목 선택적 적용)

④측량, 토질조사 및 시험은 별도 관련품을 적용한다.

⑤ 각종 영향 검토서는 별도의 각종 영향평가 업무 또는 각종 영향검토서의 내용을 정리 요약하는 것으로 한다.

3-6 주요업무내용

1. 도시·군관리계획(재정비)

구 분		업무내용	내 용
1.조사분석	1)기초조사		·도시·군기본계획 수립지침에 규정된 조사방법을 준용 ·제3장제8절 도시계획 기초조사 업무내용 참조
2.기본구상	1)계획의 배경	①계획의 성격	·목적과 필요성 ·계획기간 ·계획연혁 ·계획수립 원칙
		②계획의 특성	·시·군의 위치와 성격 ·시·군고유의 특수성 ·시·군세력권 ·시·군개발잠재력
		③기존계획의 검토	·광역도시계획 및 도시·군기본계획 검토 ·기결정된 도시·군관리계획 검토
	2)시·군의 장기 발전 구상	①도시개발의 기본 목표와 전략	·개발목표 설정 ·목표실현을 위한 전략
		②계획의 목표와 지표설정	·시·군의 미래상 전망 ·인구지표 ·경제지표 ·환경지표
		③공간구조의 설정	·공간구조의 설정 ·생활권 설정 및 인구배분계획
3.부문별계획	1)용도지역·지구·구역계획	①용도지역	·용도지역의 조정 및 입안
		②용도지구	·용도지구의 검토 및 지정
		③용도구역	·용도구역의 검토 및 지정
	2)기반시설 계획	①교통시설	·도로 ·철도 ·항만 ·공항 ·주차장 ·자동차정류장 ·궤도 ·운하 ·자동차 및 건설기계검사시설 ·자동차 및 건설기계운전학원 등
		②공간시설	·광장 ·공원 ·녹지 ·유원지 ·공공공지 등

구 분		업무내용	내 용
3.부문별계획 (계속)	2)기반시설 계획	③유통·공급시설	·유통업무설비 ·수도공급설비 ·전기공급설비 ·가스공급설비 ·열공급설비 ·방송·통신시설 ·공동구 ·시장 ·유류저장 및 송유설비 등
		④공공·문화체육시설	·학교 ·운동장 ·공공청사 ·문화시설 ·체육시설 ·도서관 ·연구시설 ·사회복지시설 ·공공직업훈련시설 ·청소년수련시설 등
		⑤방재시설	·하천 ·유수지 ·저수지 ·방화설비 ·방풍설비 ·방수설비 ·사방설비 ·방조설비 등
		⑥보건위생시설	·화장시설 ·공동묘지 ·납골시설 ·자연장지 ·도축장 ·종합의료시설 등
		⑦안전계획	·재해발생의 특성조사 ·방재계획 수립
		⑧방범계획	·범죄유발 환경요소 제거 ·토지이용계획에 반영
		⑨환경기초시설	·하수도 ·폐기물처리시설 ·수질오염방지시설 ·폐차장
	3)도시개발계획	①시가화용지의 개발	·개발방향 및 수법 ·기존 및 신시가지의 균형개발계획
		②시가화 예정 용지의 개발	·개발방향 및 수법 ·장래 신시가지의 균형개발계획

2. 도시·군관리계획(변경)결정 (부분·단위)

구 분	업무내용	내 용
1.계획검토	①관련법규 및 계획검토	·도시·군계획시설(변경)결정에 필요한 관계법 및 도시·군계획시설 변경과 관련된 상위 및 관련계획 검토
	②주변지역과의 상관성 검토	·당해 지역과 주변지역 관련사항
2.도시·군계획시설(변경) 결정도서 작성	①도시·군계획시설(변경) 결정 조서	·도시·군계획시설(변경)결정에 따른 상세조서 작성
	②도시·군계획시설(변경) 결정 사유서 및 개발(사업)계획서	·도시·군계획시설(변경)결정의 사유서 및 변경이 요구되는 개발(사업)계획서의 요약 정리 ·사업시행자, 시행방법, 시행기간, 세부사업계획(토지이용계획, 주요시설계획, 기반시설, 조경계획, 우·오수처리계획 등), 투자계획, 현황사진, 기타 참고사항 등
	③각종 영향 검토	·도시·군계획시설(변경)결정 후 시설 등의 설치로 자연경관 훼손, 생태계변화 및 오염의 배출, 교통문제 등에 따른 각종 영향을 예측하고 방지대책 요약정리
	④공고에 따른 의견내용 및 조치결과 작성	·계획 공람공고시 제출된 의견에 대한 조치계획 작성
	⑤도시·군계획시설(변경) 변경도 작성	·위치도, 도시·군계획시설(변경)결정도, 지형고시도 등 작성
	⑥시설배치 및 토지이용계획	·지적이 표시된 도면에 작성
	⑦지적도 및 토지조서, 권리 조서 등 작성	·총괄표 및 세부조서로 구분작성 ·총괄표는 행정구역 및 지목별로 구분작성 ·농지에 대하여는 농업진흥구역인 농지·농업보호구역인 농지와 농업진흥지역이 아닌 농지로, 산림에 대하여는 보전임지 및 준보전임지로 구분 기재

3-7 표준성과품

1. 도시·군관리계획(재정비)

성과구분	표준성과도서			비 고
	구 분	규 격	제출부수	
계획도	·도시·군관리계획 결정도 ·도시·군관리계획 총괄도	1/5,000 1/25,000	2부 5부	
도시·군관리계획 (변경)결정조서	·도시·군관리계획의 결정조서 ·도시·군관리계획 입안기초조사 관계서류 ·지방의회 의견서 및 주민청취에 관한 서류 ·관계부서 협의서류 및 도면 ·연차별 집행계획 및 재원조달계획		5부 1부 각 1부 각 2부 1부	참고
보고서	·도시·군관리계획 계획서		30부	
참고도서	·도시·군관리계획의 토지이용현황도서 ·도시·군관리계획의 시설현황도 ·도시·군관리계획 결정에 필요한 구비서류	1/25,000 1/25,000	1부 1부 1부	

주 : ①제출부수 및 성과품 종류가 증가할 경우에는 증가배수에 해당하는 작업품과 비용을 가산한다.
②계획보고서 및 기타 관련자료의 규격 및 제출부수는 발주자와의 협의에 의하여 비용을 산정한다.

2. 도시·군관리계획(변경)결정(단위)

성과구분	표준성과도서			비 고
	구 분	규 격	제출부수	
도시·군계획시설(변경)결정서류		기준단위	3부	
각종도면	·도시·군관리계획 총괄도(위치도) ·도시·군계획시설(변경)결정도 ·지형도면고시도 ·시설배치 및 개발계획도 ·지적도 ·농지전용협의도 ·산지,초지편입 현황도	1/25,000이상 1/25,000이상 1/1,200이상 1/5,000이상 1/5,000이상 1/5,000이상 1/5,000이상	1부 1부 1부 1부 1부 1부 1부	
도시·군관리계획 (변경)결정조서	·도시·군관리계획(변경)결정 조서 ·토지조서 ·농지조서 ·산지조서 ·초지조서		1부 1부 1부 1부 1부	

주 : ①제출부수 및 성과품 종류가 증가할 경우에는 증가배수에 해당하는 작업품과 비용을 가산한다.
②계획보고서 및 기타 관련자료의 규격 및 제출부수는 발주자와의 협의에 의하여 비용을 산정한다.

제4절 도시(지역)교통계획

4-1 정 의

○ 도시(지역)교통계획은 「도시ㆍ군기본계획 수립지침」에 따라 도시ㆍ군기본계획보고서와 병행하여 별도로 작성 계획하는 교통계획(수립보고서)으로서 당해 지역의 도시·군기본계획 개요, 교통시설현황 등의 분석을 통하여 목표년도에 교통계획지표를 설정하고 기능별 가로망계획, 교통시설계획, 교통시설운영계획 등을 작성함으로써 도시계획에 있어서 교통계획이 보다 심도 있게 수립되도록 추진되는 도시계획의 일부이다.

4-2 자료제공의 전제

○ 당해 계획의 수립에 필요한 모든 관련자료는 원칙적으로 발주자가 제공하는 것으로 하되, 발주자가 보유하지 않는 자료는 엔지니어링사업자가 조사·수집한다.

○ 발주자가 제공하지 못하는 자료의 조사에 있어서는 그 규모·내용에 의거하여 별도의 엔지니어링사업대가를 산정하여 엔지니어링사업자가 수행하며, 당해 관련자료의 기밀성과 광범위한 자료가 요구될 경우에는 조사·분석에 필요한 상당기간과 자료수집비용이 전제되어야 한다.

4-3 품 산정의 원단위 산정과 기준

4-3-1 표준품 산정내역

○ 표준품 산정의 기준이 되는 비목은 제1장 총칙에서 제시한 비목을 중심으로 하였으며, 이는 도시(지역)교통계획수립에 필요한 사항만을 대상으로 한다.

○ 표준품 산정의 기준이 되는 직접인건비 품의 작업항목별 보할은 업무의 난이도를 감안하여 설정토록 한다.

종 별		내 용	단 위	비 고
직접비	직접인건비	1.서 론 2.도시ㆍ군(지역)기본계획 개요 3.교통시설 현황분석 4.교통시설계획 5.교통시설운영계획 6.성과품작성 7.기술협의	인·일 〃 〃 〃 〃 〃 〃	
	직접경비	여비, 인쇄비, 조감도, 회의준비비, 현장운영비 등	식	제1장 총칙참조
간접비	제경비	(직접인건비)×120%	〃	〃
	기술료	(직접인건비+제경비) ×25%	〃	〃

4-3-2 산정 기준

1. 계획·기준인구의 설정

○ 기준인구는 전국 도시의 인구분포를 분석하여 도시인구 5만인으로 하였으며, 직능별 직접인력 소요 원단위는 기 작성된 시·군의 도시・군기본계획 등의 투입기술자 비율을 감안하여 설정하였다.

○ 계획인구는 당해 도시권의 목표인구를 원칙으로 한다.

2. 표준품의 산정방법

○ 표준품의 적용에 있어 기준인구와 계획인구의 차이에 따른 품 산정은 아래의 수정식에 따라 기준인구의 소요작업량을 수정하여 산정한다.

○ 소요작업량 = 기준인구 소요작업량 × 인구보정계수(α)

3. 계획안의 수정과 과업중지에 따른 품 산정방법

○ 계획안이 작성되고 보고, 협의, 공청회, 주민설명회 등의 모든 제반의 기술협의 및 행정절차과정을 거쳐 계획안이 확정된 후 발주자의 사정에 의하여 계획안이 일부변경·재작업이 수행되는 경우에는 그 변경・재작업의 정도에 따라 엔지니어링사업대가의 50～100% 수준에서 비용을 추가 지급하여야 한다.

○ 과업수행 중 발주자의 사정에 따른 과업 중단으로 인해 정부 회계연도가 경과되어 현저한 비용의 차이가 발생하였을 경우에는 엔지니어링사업대가를 당해 신년도의 노임단가를 기준으로 재산정하여야 한다.

4-3-3 단위별 변화수정과 보정

1. 인구의 대소에 대한 작업량 보정계수 산정

○ 도시의 계획인구가 기준인구를 초과하거나 못 미치는 경우의 직접인력 소요작업량의 산정을 위한 보정계수(α)는 다음의 식에 의해 산정한다.

$$\alpha = \left(\frac{\text{계획인구}}{\text{기준인구}}\right)^{0.5} = \left(\frac{A}{5}\right)^{0.5}$$

α = 보정계수
A = 계획인구(만인)

계획단위 인구별 보정계수

계획인구(만인)	보정계수(α)	계획인구(만인)	보정계수(α)
1	0.447	50	3.162
3	0.775	100	4.472
5	1.000	150	5.477
10	1.414	200	6.325
20	2.000	300	7.746

주 : 계획인구가 1만인 미만인 경우에는 계획인구 1만인을 기준으로 하여 산정한다.

2. 직접인건비 소요 작업량 산정

○ 계획인구의 대소에 따른 직접인력 소요작업량의 산정방법은 아래와 같이 기준인구의 직능별 직접인력 소요작업량에 계획단위인구의 보정계수(α)를 곱하여 산출한다.

구 분	기준인구 (만인)	총작업량(인·일)					
		기술사	특 급	고 급	중 급	초 급	보조원
도시(지역) 교통계획	5	13.0α	25.0α	46.0α	62.0α	112.0α	142.0α

4-4 표준단위 업무분류와 원단위

기술업무의 직능별 직접인력 소요작업량(인구5만인 기준)

(단위 : 인 · 일/표준단위)

구 분	업무내용	표준단위	소요인력						비고
			기술사	특 급	고 급	중 급	초 급	보조원	
1.서 론	①목 적 ②범 위 ③계획수립 방법	5만인 5만인 5만인	0.2 0.1 0.2	0.3 0.2 0.3	0.4 0.5 0.5	0.6 0.6 0.7	1.1 1.1 1.2	1.4 1.4 1.5	주1
	소 계		0.5	0.8	1.4	1.9	3.4	4.3	
2.도시(지역) 기본 계획 개요	①계획구역 ②도시(지역)구조 ③토지이용계획 ④주요시설계획 등	5만인 5만인 5만인 5만인	0.1 0.2 0.3 0.2	0.2 0.5 0.5 0.3	0.4 0.9 0.9 0.5	0.6 0.7 0.6 0.6	1.1 1.1 1.1 1.2	1.4 1.4 1.5 1.4	주1
	소 계		0.8	1.5	2.7	2.5	4.5	5.7	
3.교통시설 현황분석	①교통시설계획 및 시설현황 ②교통처리 ③교통수단별 운영 ④기 타	5만인 5만인 5만인 5만인	0.9 0.9 0.6 0.6	1.7 1.7 1.2 1.2	3.2 2.8 2.3 2.3	5.0 3.7 3.7 4.3	9.0 6.7 6.7 7.8	14.2 12.8 12.8 9.9	
	소 계		3.0	5.8	10.6	16.7	30.2	49.7	
4.교통시설 계획	①교통계획지표설정 ②간선도로망계획 ③보조간선도로망계획 ④기능별 가로망계획 ⑤도로 교차지점계획 ⑥기타 교통시설계획	5만인 5만인 5만인 5만인 5만인 5만인	1.9 0.8 0.7 1.1 1.3 1.1	3.8 1.7 1.5 2.3 2.0 2.2	6.9 3.2 2.7 4.2 3.7 4.1	5.0 5.0 5.0 6.2 6.2 6.1	9.0 9.0 9.0 11.2 11.2 11.1	11.4 12.8 12.8 8.5 12.8 12.7	
	소 계		6.9	13.5	24.8	33.5	60.5	71.0	
5.교통시설 운영계획	①간선도로망 기능유지 ②교통체계관리 ③대중교통수단	5만인 5만인 5만인	0.5 0.6 0.4	1.0 1.0 0.7	1.8 1.8 1.5	1.3 1.2 1.2	2.3 2.2 2.2	1.5 1.4 2.8	
	소 계		1.5	2.7	5.1	3.7	6.7	5.7	
6.성과품작성	보고서작성 및 편집	5만인	0.3	0.7	1.4	3.7	6.7	5.6	
	소 계		0.3	0.7	1.4	3.7	6.7	5.6	
총 계			13.0	25.0	46.0	62.0	112.0	142.0	
7.기술협의	①공청회/주민설명회 ②주민간담회/시민계획단 ③위원회심의 지원 ④관계기관 협의	1식 1식 1식 1식	2.0 2.0 2.0 2.0	2.0 2.0 2.0 2.0	2.0 2.0 2.0 2.0	4.0 4.0 4.0 4.0	4.0 4.0 4.0 4.0	4.0 4.0 4.0 4.0	주2
	소 계		8.0	8.0	8.0	16.0	16.0	16.0	

주 : ①도시 및 지역계획 등과 단일건으로 발주할 경우에는 "1.서론, 2.도시(지역)기본계획 개요"에 대하여는 기술자 투입인력을 60% 감할 수 있다.

②기술협의는 2회 이내 기준이며, 횟수가 늘어날 경우 증가배수에 해당하는 작업품과 비용을 가산한다. (필요항목 선택적 적용)

4-5 주요업무내용

구 분	업무내용	내 용
1.서 론	①목 적	
	②범 위	· 계획의 공간적, 시간적, 내용적 범위를 설정
	③계획수립방법	
2.도시(지역) 기본계획개요	①계획구역	
	②도시(지역)구조	
	③토지이용계획	
	④주요시설계획 등	
3.교통시설 현황분석	①교통시설계획 및 시설현황	·도시 · 군(지역)계획상의 기능별 도로, 철도, 교통광장, 주차장 등 교통시설계획의 현황 및 개설현황과 문제점을 분석한다. (도로율, 도로연장, 밀도, 교차로구조 등)
	②교통처리	·도시(지역)내 교통의 특성과 교통소통현황 및 교통소통상의 애로원인을 기능별 가로망구조, 교통시설의 공급, 구조적 결함, 토지이용의 패턴 등을 체계적으로 분석하고 장래를 전망한다. ·특히, 간선도로에 대하여는 기능유지에 장애되는 요소를 구체적으로 분석한다.
	③교통수단별 운영	·버스, 지하철 등의 운영실태와 이에 따른 도시·군(지역) 계획상의 과제를 분석한다.
	④기 타	·기타 교통시설의 현황과 문제점을 분석한다.
4.교통시설 계획	①교통계획지표 설정	·지하철, 도로 등 교통시설별 교통분담, 서비스수준, 교통시설 등의 지표를 설정한다.
	②간선도로망계획	·지역간 및 당해 시·군내 지역간을 연결하는 간선도로망 체계를 구성한다. ·지역간 도로는 시가지를 우회 처리하도록 계획하고 가로망구조는 가급적 순환도로망 체계를 구성하도록 한다.
	③보조간선도로망 계획	·지역간 및 당해 도시내 지역간을 연결하는 보조간선도로망체계를 구성한다.
	④기능별가로망계획	· 기능별 도로의 배치 및 규모에 대한 원칙을 제시하되, 도시·군계획수립시 지침이 될 수 있도록 특성화시킨다. ·역세권 등 도시내 지역별 도로배치 및 규모 등에 관한 도로계획수립지침을 제시한다. ·보행자전용도로, 자전거전용도로는 도시내 녹지체계와 관련하여 계획한다.
	⑤도로교차지점계획	·간선도로의 교차지점에 대한 구조 등 교통처리방안을 제시한다.
	⑥기타교통시설계획	·철도(지하철 포함), 경전철, 공항, 주차장, 환승시설, 자동차정류장 등 교통시설에 관한 계획 또는 계획수립방향을 제시한다.

구 분	업무내용	내 용
5.교통시설 운영 계획	①간선도로망 기능유지	·도로구조, 교차로 구조개선, 도로변 토지이용규제방안 등 간선도로의 기능유지를 위한 도시·군계획상 대책방안을 제시한다.
	②교통체계관리	·각 교통수단 및 시설의 관리방안을 제시한다.
	③대중교통수단	·TSM 대상시설 및 운영방향을 제시한다. ·버스, 지하철, 택시, 경전철 등 운영방향 및 이에 따른 도시 · 군계획상의 고려사항을 제시한다.

4-6 표준성과품

성과구분	표준성과도서			비 고
	구 분	규 격	제출부수	
현황도	·간선교통망 현황도 ·주요 교통시설 현황도	1/25,000 또는 1/50,000 1/25,000 또는 1/50,000	1부 1부	
계획도	·간선교통망 계획도 ·주요 교통시설 계획도	1/25,000 또는 1/50,000 1/25,000 또는 1/50,000	2부 2부	
보고서	·교통계획 보고서			발주자 협의

주 : ①제출부수 및 성과품 종류가 증가할 경우에는 증가배수에 해당하는 작업품과 비용을 가산한다.
②계획보고서 및 기타 관련자료의 규격 및 제출부수는 발주자와의 협의에 의하여 비용을 산정한다.

제5절 지형도면고시계획

5-1 정 의

○ 지형도면고시계획은 도시계획 등에 의하여 결정 고시된 내용을 지적이 표시된 지형현황도상에 명시하는 도시계획 확정작업이다.

5-2 자료제공의 전제

○ 당해 계획의 수립에 필요한 모든 관련자료는 원칙적으로 발주자가 제공하여야 한다.

○ 지형도면고시계획에 필요한 지형현황도 작성을 위한 측량 및 도면작성비용은 지형도면고시계획비와는 별도로 산정되어야 한다.

5-3 업무범위와 추진과정

5-3-1 업무범위

○ 도시계획구역내의 지형지물과 지적이 동시에 표시된 현황실측도상에 용도지역, 지구, 구역 및 도로, 공원, 녹지 등의 도시·군계획시설에 대하여 위치, 면적, 선형 등을 정확(5% 이내의 오차허용)하게 확정 수록한 계획도면과 계획조서 및 기타 참고도서 등을 작성한다.

5-3-2 추진과정

○ 도시계획 결정고시가 지연되는 경우에는 과업수행기간에서 제외하며, 그 소요기간 만큼 과업수행기간을 연장하여야 한다.

1. 계획수립추진과정

2. 과업수행추진과정

현황측량 및 관련자료조사

↓

관련계획 및 이용현황분석·검토

↓

계획대상에 대한 위치 면적 선형확정 도시(圖示)

↓

도면 및 조서작성

↓

점 검 정 리

↓

확 정 고 시

5-4 품 산정의 원단위 산정과 기준

5-4-1 표준품 산정내역

○ 표준품 산정의 기준이 되는 비목은 제1장 총칙에서 제시한 비목을 중심으로 하였으며, 이는 지형도면고시에 필요한 사항만을 대상으로 한다.

○ 표준품 산정의 기준이 되는 직접인건비 품의 작업항목별 보할은 기존의 경험적 내용 및 항목별 업무의 난이도를 감안하여 설정토록 한다.

종 별		내 용	세부항목	단 위	비 고
직접비	직접인건비	1.조사분석	①상위관련계획 분석 및 이용상황 검토	인·일	
		2.지형도면 고시계획	①위치, 면적, 선형확정도시 ②조서, 도면작성 ③검토정리	〃 〃 〃	
		3.성과품 작성	①토지이용계획확인서 도면작성 (KLIS 등재)	〃	
		4.기술협의	①공청회/주민설명회 ②주민간담회/시민계획단 ③위원회심의 지원 ④관계기관 협의	〃 〃 〃 〃	
	직접경비	여비, 인쇄비, 조감도, 회의준비비, 현장 운영비 등		식	제1장 총칙참조
간접비	제경비	(직접인건비) × 110%		〃	〃
	기술료	(직접인건비+제경비) × 20%		〃	〃

주 : 조사측량비는 측량비품에 의해 별도 산정한다.

5-4-2 산정 기준

1. 계획·기준면적의 설정

○ 기준면적은 축척 1/500～1/600 도면과 시가화구역(주거지역, 상업지역, 공업지역)의 면적 10만㎡로 하였으며, 직능별 직접인력 소요원단위는 기 작성된 지형도면고시계획 등의 투입기술자 비율을 감안하여 설정하였다.

○ 계획면적설정은 다음과 같이 한다

계획 면적 산정 예시

•시가화구역은 과업면적을 대상으로 한다. •시가화구역 이외의 지역에서 선으로 표시되는 도시·군계획시설에 대하여는 계획선 양측 50m이내를 면적범위로 보며, 이때의 산정은 본 산정의 50%를 적용한다. 예) ①도로(폭 30m)가 자연녹지지역내에서 계획연장이 500m일 경우 이 도로에 대한 지형도면고시계획면적은 다음과 같다. {도로폭(30m) + 도로계획선 양측 각 50m(100m)} × 도로연장(500m) = 65,000㎡ ②공원이 자연녹지지역내에 있고 공원구역경계선만의 확정이 필요한 경우 지형도면고시계획면적은 다음과 같다. 공원경계선연장 × 경계선양측 각 50m(100m) = 지형도면고시계획면적 ※ 단, (공원계획선 연장×50m ≦ 계획공원면적)의 부등식이 성립될 경우 지형도면고시계획면적은 (공원경계선연장 × 50m + 계획공원면적)으로 한다. ③도시계획구역계만의 확정이 필요한 경우 지형도면고시면적은 다음과 같다. 도시계획구역선 연장 × 경계선 양측 각 50m(100m) = 지형도면고시계획면적 •시가화로 개발되어 있을 경우, 그 면적에 대하여는 표준산정내역의 “1-①.상위관련계획 분석 및 이용상황검토”에 대한 품을 삭감할 수 있다. 예) 시가화구역 면적이 5.0㎢이고, 이중 도시계획사업(계획적 시가화 조성사업)을 시행한 지역이 2.0㎢인 경우 3.0㎢에 대하여는 계획비 전체(1～5항)를 적용하고 2.0㎢에 대하여는 2～5항만 적용한다. •시가화(市街化)구역과 녹지지역에 접한 경우에는 녹지지역쪽으로 50m를 추가하여 시가화구역 지형도면고시 면적으로 한다. 예) 시가화구역과 녹지지역이 접한 경계선 길이 × 50m •선으로 표시되는 도시·군계획시설 중 기정계획에 대하여 변경이 없는 경우는 2～5항만 적용한다.

2. 표준품의 산정방법

○ 표준품의 적용에 있어 기준면적과 계획면적의 차이, 도면축척의 변화에 따른 품 산정은 아래의 수정식에 따라 기준면적의 소요작업량을 수정하여 산정한다.

○ 소요작업량 = 기준면적 소요작업량×면적보정계수(α)×축척보정계수(β)

3. 계획안의 수정과 과업중지에 따른 품 산정방법

○ 계획안이 작성되고 주민공람, 의회보고 등 행정절차과정을 거쳐 계획안이 확정된 후 발주자의 사정에 의하여 계획안이 일부변경·재작업이 수행되는 경우에는 그 변경·재작업의 정도에 따라 엔지니어링사업대가의 50～100% 수준에서 비용을 추가 지급하여야 한다.

○ 과업수행 중 발주자의 사정에 따른 과업 중단으로 인해 정부 회계연도가 경과되어 현저한 비용의 차이가 발생하였을 경우에는 엔지니어링사업대가를 당해 신년도의 노임단가를 기준으로 재산정하여야 한다.

5-4-3 단위별 변화수정과 보정

1. 작업량 보정계수 산정

1) 면적의 대소에 대한 작업량 보정계수 산정

○ 계획면적이 기준면적을 초과하거나 못 미치는 경우의 직접인력 소요작업량의 산정을 위한 면적보정계수(α)는 다음의 식에 의해 산정 한다.

$$\alpha = \left(\frac{\text{계획면적}}{\text{기준면적}}\right)^{1.0} = \left(\frac{A}{10}\right)^{1.0}$$

α = 보정계수
A = 계획면적(만㎡)

계획단위 면적별 보정계수

계획면적(만㎡)	보정계수(α)	계획면적(만㎡)	보정계수(α)
3	0.300	40	4.000
5	0.500	60	6.000
10	1.000	80	8.000
15	1.500	100	10.000
20	2.000	200	20.000

주 : 계획면적이 3만㎡ 미만인 경우에는 계획면적 3만㎡를 기준으로 하여 산정한다.

2) 도면축척 변화에 따른 보정계수 산정

○ 작업축척이 본 품은 기준축척 1/500～1/600과 다를 경우 직접인력 소요작업량의 산정을 위한 축척보정계수(β)는 다음표와 같다.

도면축척변화에 따른 보정계수

축 척	보정계수(β)
1/500～1/600	1.0
1/1,000～1/1,200	0.7
1/2,500	0.5

2. 직접인건비 소요 작업량 산정

○ 지형도면고시계획 직접인력 소요작업량의 산정방법은 아래와 같이 기준면적의 직능별 직접인력 소요작업량에 계획단위면적의 보정계수(α)와 도면축척변화 보정계수(β)를 곱하여 산출한다.

구 분	기준면적 기준축척	총작업량(인·일)					
		기술사	특 급	고 급	중 급	초 급	보조원
지형도면 고시계획	10만㎡ 1/500～1/600	1.0αβ	2.0αβ	4.5αβ	8.0αβ	10.0αβ	13.0αβ

5-5 표준단위 업무분류와 원단위

기술업무의 직능별 직접인력 소요작업량 (면적 10만㎡, 축척 1/500~1/600 기준)

(단위 : 인·일/표준단위)

구 분	업무내용	표준 단위	소요인력						비고
			기술사	특 급	고 급	중 급	초 급	보조원	
1.조사분석	①상위관련계획 분석 및 이용 상황 검토	10만㎡외	0.2	0.4	0.5	1.0	1.0	1.0	
	소 계		0.2	0.4	0.5	1.0	1.0	1.0	
2.지형도면 고시계획	①위치, 면적, 선형확정도시	10만㎡외	0.4	0.8	1.0	2.0	3.0	4.0	
	②조서, 도면작성	10만㎡외	-	-	1.0	2.0	3.0	4.0	
	③검토정리	10만㎡외	0.2	0.4	1.0	1.0	-	-	
	소 계		0.6	1.2	3.0	5.0	6.0	8.0	
3.성과품작성	①토지이용계획확인서 도면작성 (KLIS 등재)	10만㎡외	0.2	0.4	1.0	2.0	3.0	4.0	
	소 계		0.2	0.4	1.0	2.0	3.0	4.0	
총계			1.0	2.0	4.5	8.0	10.0	13.0	
4.기술협의	①공청회/주민설명회	1식	2.0	2.0	2.0	4.0	4.0	4.0	주1
	②주민간담회/시민계획단	1식	2.0	2.0	2.0	4.0	4.0	4.0	
	③위원회심의 지원	1식	2.0	2.0	2.0	4.0	4.0	4.0	
	④관계기관 협의	1식	2.0	2.0	2.0	4.0	4.0	4.0	
	소 계		8.0	8.0	8.0	16.0	16.0	16.0	

주 : ①기술협의는 2회 이내 기준이며, 횟수가 늘어날 경우 증가배수에 해당하는 작업품과 비용을 가산한다. (필요항목 선택적 적용)

②지형도면고시계획의 현황조사측량에 대하여는 총칙에 따라 측량품을 적용하여 산정한다.

5-6 주요업무내용

구 분	업무내용	내 용
1.조사분석	①상위관련계획 분석 및 이용 상황 검토	·도시계획재정비의 검토, 분석 ·공원계획, 유원지계획 등 도시·군계획시설내용 검토 ·기존지형도면고시 및 토지이용계획확인서 검토 ·기존도로 및 주요시설물의 이용상황검토 ·상수도시설 등 지형도면고시계획선 확정에 영향을 주는 시설의 현황 및 계획검토
2.지형도면 고시계획	①위치, 면적, 선형확정 도시	·용도지역, 지구, 구역의 경계선 확정도시 ·면적으로 표시되는 도시·군계획시설의 면적확인 및 경계선 확정도시(예: 공원, 유원지) ·선으로 표시되는 도시·군계획시설의 선형확정도시(예: 도로, 시설녹지) ·시가화구역내의 소로계획확정 도시
	②조서, 도면작성	·위치 및 선형의 확정에 의하여 고시할 도면을 필요 부수만큼 작성 ·계획도면에는 용도지역, 지구, 구역, 도시·군계획시설에 대하여 선, 채색, 명칭 등 제반 필요사항이 표시되어야 함. ·조서의 작성에는 용도지역, 지구, 구역, 각 도시 계획시설의 조서양식에 의하여 위치, 면적, 길이 등을 기입
	③검토정리	·도면의 확인, 조서의 확인, 도면과 조서를 대조 확인한다. ·도면과 조서 등을 일건 서류로서 정리한다.

5-7 표준성과품

성과구분	표준성과도서			비 고
	구 분	규 격	제출부수	
계획도	·지형도면고시종합계획도 ·시설계획도(필요한경우)	1/500～1/6,000 1/500～1/6,000	1부 1부	
조 서	·지형도면고시조서	발주자와 협의	1부	

주 : 제출부수 및 성과품 종류가 증가할 경우에는 증가배수에 해당하는 작업품과 비용을 가산한다.

제6절 단계별집행계획

6-1 정 의

○ 단계별 집행계획은 시민편의를 위한 필수기반시설인 도시·군계획시설을 설치·정비·개량하기 위하여 수립하는 계획이다.

○ 도시·군관리계획으로 결정된 개별 도시·군계획시설에 대하여 도시·군계획시설사업을 효율적이고, 체계적으로 집행 및 관리하기 위하여 단계별집행계획을 수립한다.

6-2 자료제공의 전제

○ 단계별집행계획 수립에 필요한 모든 관련자료는 원칙적으로 발주자가 제공하는 것으로 하되, 발주자가 보유하지 않는 자료는 엔지니어링사업자가 조사·수집한다.

○ 발주자가 제공하지 못하는 자료의 조사에 있어서는 그 규모·내용에 의거하여 별도의 엔지니어링사업대가를 산정 엔지니어링사업자가 수행하며, 당해 관련자료의 기밀성과 광범위한 자료가 요구되는 경우 조사·분석에 필요한 상당기간과 자료수집비용이 전제되어야 한다.

6-3 업무범위와 추진과정

6-3-1 업무범위

○ 단계별 집행계획은 도시·군기본계획, 도시·군관리계획 변경(재정비)계획과 단위도시·군계획시설을 수용·발전시켜 미집행된 도시·군계획시설을 조사·분석하여 사업비추정, 타당성 검토 후 투자방안을 예측하여 단계별집행계획을 수립하는 것이다.

6-3-2 추진과정

○ 타부처(관계기관)와 협의나 전문가 자문 등에 소요되는 기간은 과업수행기간에서 제외하여 그 소요기간만큼 과업수행기간을 연장하여야 한다.

1. 계획수립추진과정

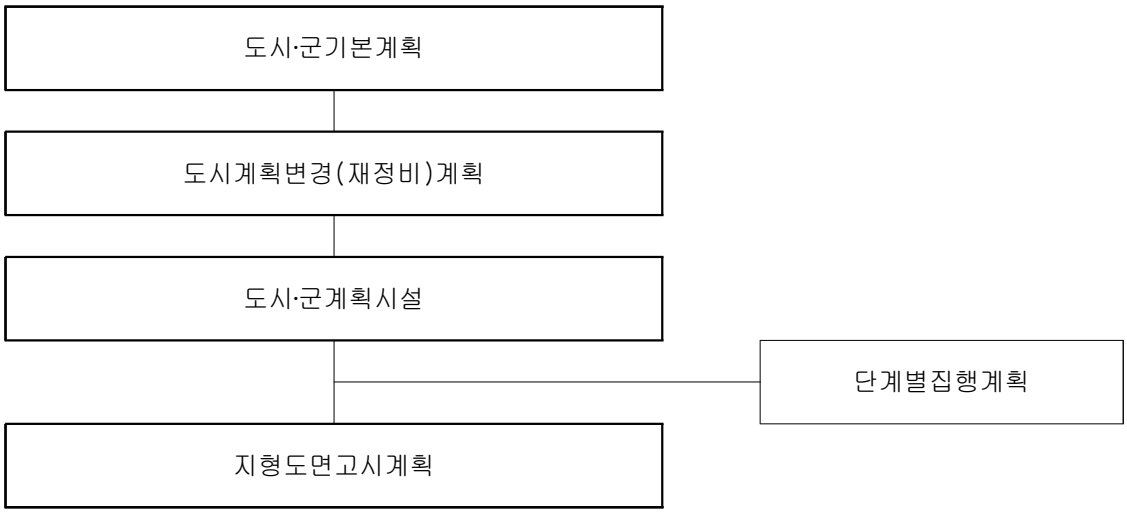

2. 과업수행추진과정

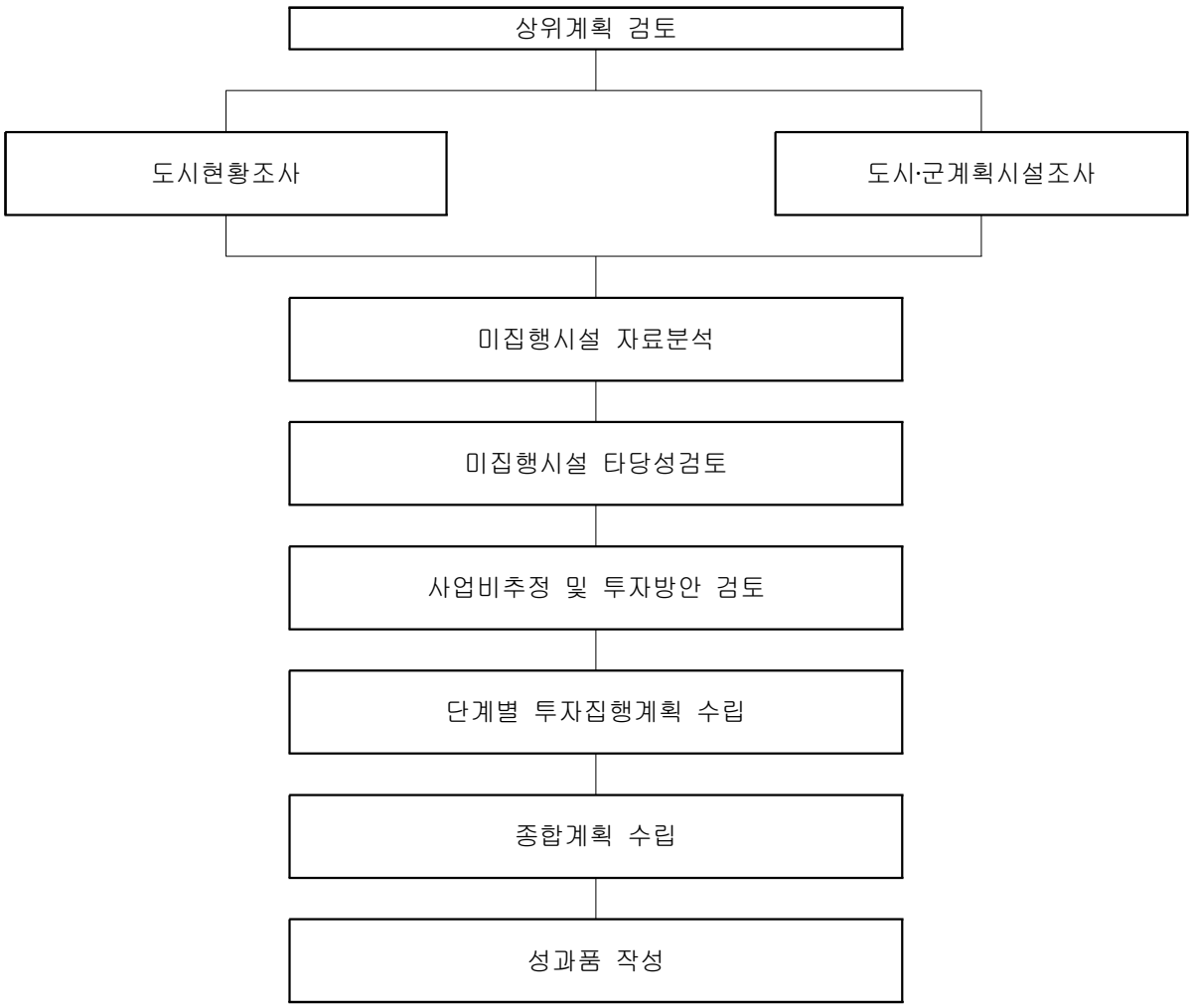

6-4 품 산정의 원단위 산정과 기준

6-4-1 표준품 산정내역

○ 표준품 산정의 기준이 되는 비목은 제1장 총칙에서 제시한 비목을 중심으로 하였으며, 이는 단계별집행계획수립에 필요한 사항만을 대상으로 한다.

○ 표준품 산정의 기준이 되는 직접인건비 품의 작업항목별 보할은 기존의 경험적 내용 및 항목별 업무의 난이도를 감안하여 설정토록 한다.

종 별		내 용	세부항목	단 위	비 고
직접비	직접인건비	1.조사·분석	①현황조사 ②분석·평가·진단	인·일 〃	측량은 별도의 관련품을 적용함
		2.기본구상	①기본구상	〃	
		3.단계별 집행계획	①단계별집행계획	〃	
		4.성과품 작성	①보고서작성 및 편집 ②관련도서작성	〃 〃	
		5.기술협의	①공청회/주민설명회 ②주민간담회/시민계획단 ③위원회심의 지원 ④관계기관 협의	〃 〃 〃 〃	
	직접경비	여비, 인쇄비, 조감도, 회의준비비, 현장운영비 등		식	제1장 총칙참조
간접비	제경비	(직접인건비) × 110%		〃	〃
	기술료	(직접인건비+제경비) × 25%		〃	〃

6-4-2 산정기준

1. 계획·기준면적의 설정

○ 기준면적은 전국 도시면적의 분포를 분석하여 도시면적 50만㎡로 하였으며, 직능별 직접인력 소요원단위는 기 작성되었던 관련계획 등의 투입기술자 비율을 감안하여 설정하였다.

○ 계획면적은 당해 도시권의 과업면적을 원칙으로 한다.

○ 단위계획시설만을 대상으로 하는 경우의 계획·기준면적은 제3장 제3절 도시·군관리계획(변경)결정(단위)의 기준을 준용한다.

2. 표준품의 산정방법

○ 표준품의 적용에 있어 계획면적이 10만㎡이하의 경우에는 10만㎡를 적용하며, 기준면적이 10만㎡이상의 경우일 때는 아래의 수정식에 따라 대상 업무별로 단위별 변화조정과 보정에 의하여 산정토록 한다.

○ 소요작업량 = 기준면적 소요작업량 × 면적보정계수(α)

3. 계획안의 수정과 과업중지에 따른 품 산정방법

○ 계획안이 작성되고 주민공람, 의회보고 등 행정절차과정을 거쳐 계획안이 확정된 후 발주자의 사정에 의하여 계획안이 일부변경·재작업이 수행되는 경우에는 그 변경·재작업의 정도에 따라 엔지니어링사업대가의 50～100% 수준에서 비용을 추가 지급하여야 한다.

○ 과업수행 중 발주자의 사정에 따른 과업 중단으로 인해 정부 회계연도가 경과되어 현저한 비용의 차이가 발생하였을 경우에는 엔지니어링사업대가를 당해 신년도의 노임단가를 기준으로 재산정하여야 한다.

6-4-3 단위별 변화수정과 보정

1. 면적의 대소에 대한 작업량 보정계수 산정

○ 계획면적이 기준면적을 초과하거나 못 미치는 경우의 직접인력 소요작업량의 산정을 위한 면적보정계수(α)는 다음의 식에 의해 산정한다.

$$\alpha = \left(\frac{\text{계획면적}}{\text{기준면적}}\right)^{0.5} = \left(\frac{A}{50}\right)^{0.5}$$

α = 보정계수
A = 계획면적(만㎡)

$$\alpha = \left[\frac{\text{계획면적(거리)}}{\text{기준면적(거리)}}\right]^{0.5} = \left(\frac{A}{1}\right)^{0.5}$$

α = 보정계수
A = 계획면적,거리(만㎡, ㎞)

계획단위면적별 보정계수 (단계별 집행계획)

계획면적(만㎡)	보정계수(α)	계획면적(만㎡)	보정계수(α)
10	0.447	60	1.095
20	0.632	80	1.265
30	0.775	100	1.414
40	0.894	150	1.732
50	1.000	200	2.000

주 : ①계획면적이 10만㎡ 미만인 경우에는 계획면적 10만㎡를 기준으로 하여 산정한다.
②평균폭이 25m 이상의 선적시설은 면적을 기준으로 산정한다.

계획단위면적별 보정계수 (단위계획시설 집행계획)

계획면적(만㎡) 계획거리(㎞)	보정계수(α)	계획면적(만㎡) 계획거리(㎞)	보정계수(α)
1	1.000	6	2.449
2	1.414	8	2.828
3	1.732	10	3.162
4	2.000	20	4.472
5	2.236	50	7.071

주 : ①계획면적이 1만㎡ 미만인 경우에는 계획면적 1만㎡를 기준으로 하여 산정한다.
②평균폭이 25m 이상의 선적시설은 면적을 기준으로 산정한다.

2. 직접인건비 소요 작업량 산정

○ 단계별집행계획수립 직접인력 소요작업량의 산정방법은 아래와 같이 기준면적의 직능별 직접인력 소요작업량에 계획단위면적의 보정계수(α)를 곱하여 산출한다.

구 분	기준면적 기준거리	총작업량(인·일)					
		기술사	특 급	고 급	중 급	초 급	보조원
단계별 집행계획	50만㎡	24.7α	43.2α	117.3α	206.5α	208.6α	242.1α
단위계획시설 집행계획	1만㎡ 1㎞	6.0α	10.0α	29.0α	52.0α	52.0α	60.0α

6-5 표준단위 업무분류와 원단위

1. 단계별 집행계획

기술업무의 직능별 직접인력 소요작업량(면적 50만㎡ 기준)

(단위 : 인 · 일/표준단위)

구 분	업무내용	표준 단위	소요인력						비고
			기술사	특 급	고 급	중 급	초 급	보조원	
1.조사·분석	①현황조사	50만㎡	1.7	5.4	11.7	51.2	58.8	76.5	주1
	②분석·평가·진단	50만㎡	7.5	8.9	27.4	41.7	32.3	27.6	주2
	소 계		9.2	14.3	39.1	92.9	91.1	104.1	
2.기본구상	①기본구상	50만㎡	7.8	13.2	32.0	21.3	19.0	20.6	주1 주2
	소 계		7.8	13.2	32.0	21.3	19.0	20.6	
3.단계별 집행계획	①단계별집행계획	50만㎡	5.5	12.1	29.3	29.5	23.7	26.4	
	소 계		5.5	12.1	29.3	29.5	23.7	26.4	
4.성과품 작성	①보고서작성 및 편집	50만㎡	1.1	1.8	8.5	31.4	37.4	45.5	
	②관련도서작성	50만㎡	1.1	1.8	8.4	31.4	37.4	45.5	
	소 계		2.2	3.6	16.9	62.8	74.8	91.0	
총 계			24.7	43.2	117.3	206.5	208.6	242.1	
5.기술협의	①공청회/주민설명회	1식	2.0	2.0	2.0	4.0	4.0	4.0	주3
	②주민간담회/시민계획단	1식	2.0	2.0	2.0	4.0	4.0	4.0	
	③위원회심의 지원	1식	2.0	2.0	2.0	4.0	4.0	4.0	
	④관계기관 협의	1식	2.0	2.0	2.0	4.0	4.0	4.0	
	소 계		8.0	8.0	8.0	16.0	16.0	16.0	

주 : ①도시·군관리계획(재정비)계획 또는 지형도면고시계획과 단일 건으로 종합하여 발주할 경우 조사·분석과 기본구상 업무에 대하여 기술자의 투입인력을 60% 감할 수 있다.

②도시·군관리계획 변경(재정비)계획 또는 지형도면고시계획을 수행 중에 도시·군계획시설 단계별집행계획을 동일 수행자에게 수의계약에 의하여 발주하고자 할 때에 현황조사와 기본구상업무에 대하여 기술자의 투입인력을 40% 감할 수 있다.

③기술협의는 2회 이내 기준이며, 횟수가 늘어날 경우 증가배수에 해당하는 작업품과 비용을 가산한다. (필요항목 선택적 적용)

2. 단위계획시설 집행계획

기술업무의 직능별 직접인력 소요작업량(면적 1만㎡, 거리 1㎞ 기준)

(단위 : 인 · 일/표준단위)

구 분	업무내용	표준 단위	소요인력						비고
			기술사	특 급	고 급	중 급	초 급	보조원	
1.조사·분석	①현황조사	1만㎡외	0.4	1.2	2.9	12.9	14.7	19.0	주1,주2
	②분석·평가·진단	1만㎡외	1.8	2.1	6.8	10.5	8.1	6.8	
	소 계		2.2	3.3	9.7	23.4	22.8	25.8	
2.기본구상	①기본구상	1만㎡외	1.9	3.1	7.9	5.4	4.7	5.1	주1,주2
	소 계		1.9	3.1	7.9	5.4	4.7	5.1	
3.단계별 집행계획	①단계별집행계획	1만㎡외	1.3	2.8	7.2	7.4	5.9	6.5	
	소 계		1.3	2.8	7.2	7.4	5.9	6.5	
4.성과품 작성	①보고서작성 및 편집	1만㎡외	0.3	0.4	2.1	7.9	9.3	11.3	
	②관련도서작성		0.3	0.4	2.1	7.9	9.3	11.3	
	소 계		0.6	0.8	4.2	15.8	18.6	22.6	
총 계			6.0	10.0	29.0	52.0	52.0	60.0	
5.기술협의	①공청회/주민설명회	1식	2.0	2.0	2.0	4.0	4.0	4.0	주3
	②주민간담회/시민계획단	1식	2.0	2.0	2.0	4.0	4.0	4.0	
	③위원회심의 지원	1식	2.0	2.0	2.0	4.0	4.0	4.0	
	④관계기관 협의	1식	2.0	2.0	2.0	4.0	4.0	4.0	
	소 계		8.0	8.0	8.0	16.0	16.0	16.0	

주 : ①도시·군관리계획(재정비)계획 또는 지형도면고시계획과 단일 건으로 종합하여 발주할 경우 조사·분석과 기본구상업무에 대하여 기술자의 투입인력을 60% 감할 수 있다.

②도시·군관리계획 변경(재정비)계획 또는 지형도면고시계획을 수행 중에 도시·군계획시설 단계별집행계획을 동일 수행자에게 수의계약에 의하여 발주하고자 할 때에 현황조사와 기본구상업무에 대하여 기술자의 투입인력을 40% 감할 수 있다.

③기술협의는 2회 이내 기준이며, 횟수가 늘어날 경우 증가배수에 해당하는 작업품과 비용을 가산한다. (필요항목 선택적 적용)

6-6 주요업무내용

구 분	업무내용	
1.조사·분석	·시설대장조사 및 작성 ·시설집행실태조사 ·시설별 투자재원조사 ·민원사례조사 ·편입토지 현황조사 ·편입 지장물 현황조사	·도시여건 종합분석 ·현황조사 내용분석 ·사업비 추정 ·미집행시설 분류기준설정 ·시설타당성 평가·진단
2.기본구상	·상위계획 및 관련계획 검토 ·도시·군관리계획 분석정리	·시설계획 장기구상계획 ·계획방향설정 ·미집행시설 관리방안
3.단계별 집행계획	·투자우선순위 기법 및 평가 ·투자재원분석 및 전망	·투자재원 확충계획 ·단계별 투자집행계획

6-7 표준성과품

성과구분	표준성과도서			비 고
	구 분	규 격	제출부수	
현황조사분석	◦도시·군계획시설대장 -총괄목록 -색인대장 -단위도시·군계획시설조서 ◦도 면 -종합도 -상세도	A4 1/25,000 1/5,000 이상	5부 5부 5부	
미집행 도시·군계획시설	◦편입토지조서 ◦지장물 현황조서 ◦소요사업비	A4 A4 A4	5부 5부 5부	
단계별 집행계획조서	◦단계별집행계획조서	A4	5부	
보고서	◦최종 보고서 ◦최종 요약보고서		30부 30부	

주 : ①제출부수 및 성과품 종류가 증가할 경우에는 증가배수에 해당하는 작업품과 비용을 가산한다.
②계획보고서 및 기타 관련자료의 규격 및 제출부수는 발주자와의 협의에 의하여 비용을 산정한다.

제7절 개발제한구역 관리계획

7-1 정 의

○ 개발제한구역관리계획업무라 함은 개발제한구역을 관할하는 시·도지사가 개발제한구역을 종합적으로 관리하기 위하여 수립하는 계획으로서, 시·도지사 및 시장·군수·구청장은 건축물·공작물의 설치허가, 토지형질변경허가, 집단취락지구의 지정, 주민지원사업의 시행 등 개발제한구역에 의한 관리계획입안과 제반 성과도서 작성업무를 말한다.

7-2 자료제공의 전제

○ 개발제한구역 관리계획 수립에 필요한 모든 관련자료는 원칙적으로 발주자가 제공하는 것으로 하되, 발주자가 보유하지 않는 자료는 엔지니어링사업자가 조사·수집한다.

○ 발주자가 제공하지 못하는 자료의 조사에 있어서는 그 규모·내용에 의거하여 별도의 엔지니어링사업대가를 산정하여 엔지니어링사업자가 수행하며, 당해 관련자료의 기밀성과 광범위한 자료가 요구되는 경우 조사·분석에 필요한 상당기간과 자료수집비용이 전제되어야 한다.

7-3 업무범위와 추진과정

7-3-1 업무범위

○ 업무범위는 개발제한구역 관리계획의 수립 및 승인을 득하기 위하여 갖추어야 할 제반 성과도서 가운데 엔지니어링사업자의 기술적 능력이 요구되는 부분의 작성으로 한다.

7-3-2 추진과정

○ 타부처(관계기관)와 협의나 전문가 자문 등에 소요되는 기간은 과업수행기간에서 제외하여 그 소요기간만큼 과업수행기간을 연장하여야 한다.

1. 계획수립추진과정

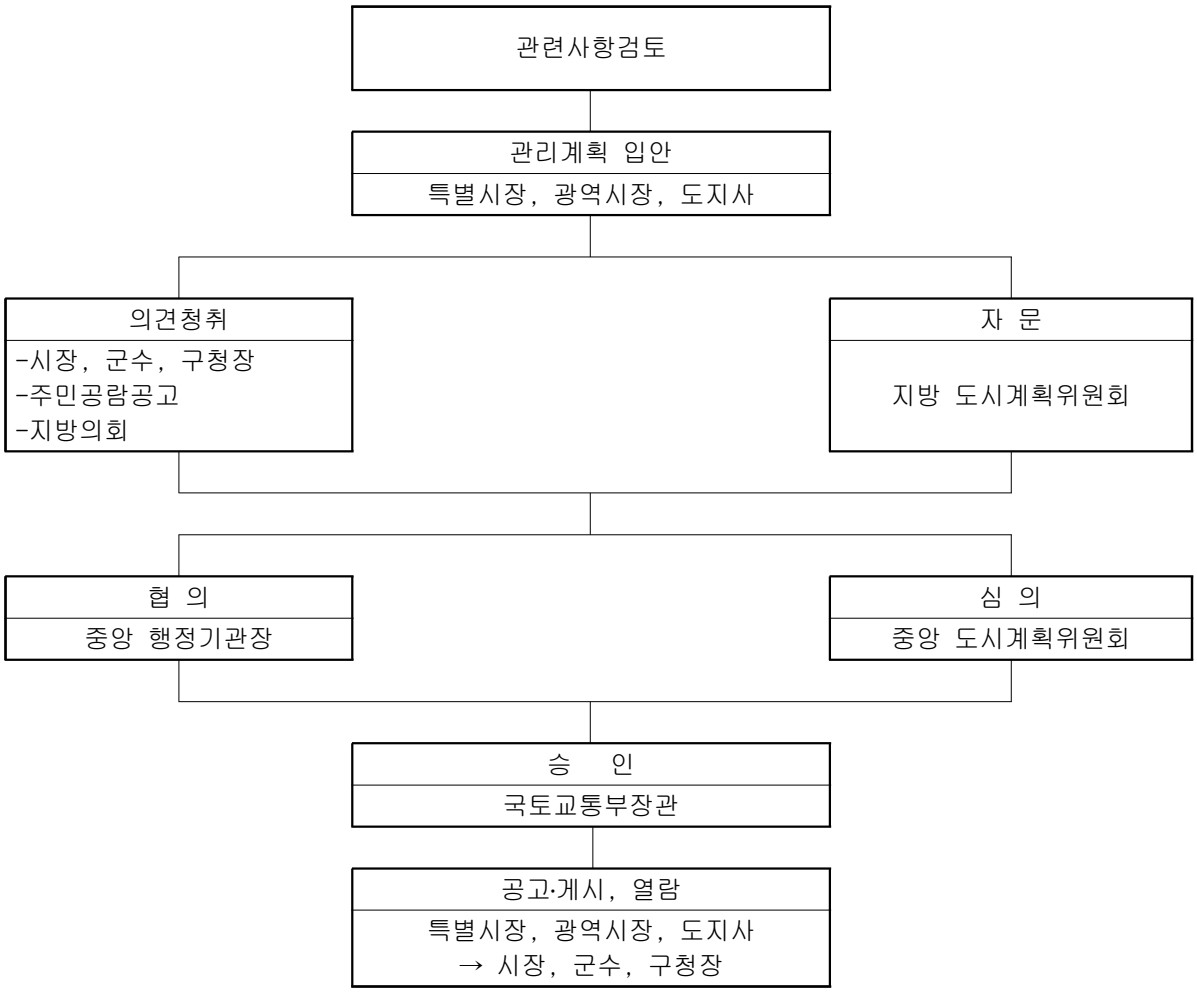

2. 과업수행추진과정

7-4 품 산정의 원단위 산정과 기준

7-4-1 표준품 산정내역

○ 표준품 산정의 기준이 되는 비목은 제1장 총칙에서 제시한 비목을 중심으로 하였으며, 이는 개발제한구역 관리계획수립에 필요한 사항만을 대상으로 한다.

○ 표준품 산정의 기준이 되는 직접인건비 품의 작업항목별 보할은 기존의 경험적 내용 및 항목별 업무의 난이도를 감안하여 설정토록 한다.

종 별		내 용	세부항목	단 위	비 고
직접비	직접인건비	1.관련사항검토	①관련법규 검토 ②관련계획 검토 ③주변지역과의 상관성 검토	인·일 〃 〃	
		2.관리계획수립	①관리목표와 기본방향 ②현황 및 실태조사 ③토지이용 및 보전 ④도시·군계획시설 설치 ⑤대규모의 건축 및 토지형질변경 ⑥취락지구 정비 ⑦주민지원사업 ⑧재원조달 및 운용 ⑨개발제한구역 해제 대상지역의 관리 ⑩환경정비 ⑪축산단지의 배치 ⑫구역관리의 전산화 ⑬위법행위의 지도, 단속, 항공사진 촬영 ⑭경계표석의 설치 ·관리 ⑮기타 필요한 사항	〃 〃 〃 〃 〃 〃 〃 〃 〃 〃 〃 〃 〃 〃 〃 〃	
		3.성과품작성	①보고서 작성 ②관련 도서작성	〃 〃	
		4.기술협의	①공청회/주민설명회 ②주민간담회/시민계획단 ③위원회심의 지원 ④관계기관 협의	〃 〃 〃 〃	
	직접경비	여비, 인쇄비, 조감도, 회의준비비, 현장 운영비 등		식	제1장 총칙참조
간접비	제경비	(직접인건비) × 120%		〃	〃
	기술료	(직접인건비+제경비) × 30%		〃	〃

7-4-2 산정기준

1. 계획·기준면적의 설정

○ 기준면적은 전국 개발제한구역면적의 분포를 분석하여 300㎢로 하였으며, 직능별 직접인력 소요원단위는 기 작성되었던 관련계획 등의 투입기술자 비율을 감안하여 설정하였다.

○ 계획면적은 당해 개발제한구역의 과업면적을 원칙으로 한다.

2. 표준품의 산정방법

○ 표준품의 적용에 있어 계획면적이 300㎢이하의 경우에는 300㎢를 적용하며, 기준 면적이 300㎢이상의 경우일 때는 아래의 수정식에 따라 대상 업무별로 단위별 변화조정과 보정에 의하여 산정토록 한다.

○ 소요작업량 = 기준면적 소요작업량 × 면적보정계수(α)

3. 계획안의 수정과 과업중지에 따른 품 산정방법

○ 계획안이 작성되고 주민공람, 의회보고 등 행정절차과정을 거쳐 계획안이 확정된 후 발주자의 사정에 의하여 계획안이 일부변경·재작업이 수행되는 경우에는 그 변경·재작업의 정도에 따라 엔지니어링사업대가의 50～100% 수준에서 비용을 추가 지급하여야 한다.

○ 과업수행 중 발주자의 사정에 따른 과업 중단으로 인해 정부 회계연도가 경과되어 현저한 비용의 차이가 발생하였을 경우에는 엔지니어링사업대가를 당해 신년도의 노임단가를 기준으로 재산정하여야 한다.

7-4-3 단위별 변화수정과 보정

1. 면적의 대소에 대한 작업량 보정계수 산정

○ 계획면적이 기준면적을 초과하거나 못 미치는 경우의 직접인력 소요작업량의 산정을 위한 면적보정계수(α)는 다음의 식에 의해 산정 한다.

$$\alpha = \left(\frac{\text{계획면적}}{\text{기준면적}}\right)^{0.5} = \left(\frac{A}{300}\right)^{0.5}$$

α = 보정계수
A = 계획면적(㎢)

계획단위면적별 보정계수

계획면적(㎢)	보정계수(α)	계획면적(㎢)	보정계수(α)
30	0.316	150	0.707
50	0.406	200	0.816
70	0.483	300	1.000
90	0.548	500	1.291
100	0.577	700	1.528

주 : 계획면적이 30㎢미만인 경우에는 계획면적 30㎢를 기준으로 하여 산정한다.

2. 직접인건비 소요 작업량 산정

○ 개발제한구역 관리계획수립 직접인력 소요작업량의 산정방법은 아래와 같이 기준면적의 직능별 직접인력 소요작업량에 계획단위면적의 보정계수(α)를 곱하여 산출한다.

구 분	기준면적 (㎢)	총작업량(인·일)					
		기술사	특 급	고 급	중 급	초 급	보조원
개발제한구역 관리계획	300	23.0α	62.0α	101.0α	156.0α	220.0α	279.0α

7-5 표준단위 업무분류와 원단위

기술업무의 직능별 직접인력 소요작업량(면적 300㎢ 기준)

(단위 : 인 · 일/표준단위)

구 분	업무내용	표준단위	소요인력						비고
			기술사	특 급	고 급	중 급	초 급	보조원	
1.관련사항검토	①관련법규 검토	300㎢	1.0	2.0	4.0	5.0	5.0	7.0	
	②관련계획 검토	300㎢	1.0	2.0	4.0	5.0	5.0	7.0	
	③주변지역과의 상관성 검토	300㎢	2.0	3.0	4.0	5.0	7.0	8.0	
	소 계		4.0	7.0	12.0	15.0	17.0	22.0	
2.관리계획 수립	①관리목표와 기본방향	300㎢	1.0	2.0	3.0	5.0	3.0	2.0	주1
	②현황 및 실태조사	300㎢	2.0	6.0	9.0	15.0	18.0	25.0	
	③토지이용 및 보전	300㎢	1.0	3.0	5.0	8.0	12.0	15.0	
	④도시·군계획시설 설치	300㎢	1.0	3.0	5.0	8.0	12.0	15.0	
	⑤대규모의 건축 및 토지형질변경	300㎢	1.0	3.0	5.0	8.0	12.0	15.0	
	⑥취락지구 정비	300㎢	1.0	3.0	5.0	8.0	12.0	15.0	
	⑦주민지원사업	300㎢	1.0	3.0	5.0	8.0	12.0	15.0	
	⑧재원조달 및 운용	300㎢	1.0	2.0	3.0	5.0	8.0	10.0	
	⑨개발제한구역 해제 대상지역의 관리	300㎢	1.0	3.0	5.0	8.0	12.0	15.0	
	⑩환경정비	300㎢	1.0	3.0	5.0	8.0	12.0	15.0	
	⑪축산단지의 배치	300㎢	1.0	3.0	5.0	8.0	12.0	15.0	
	⑫구역관리의 전산화	300㎢	1.0	3.0	5.0	8.0	12.0	15.0	
	⑬위법행위의 지도,단속,항공사진 촬영	300㎢	1.0	3.0	5.0	8.0	12.0	15.0	
	⑭경계표석의 설치·관리	300㎢	1.0	3.0	5.0	8.0	12.0	15.0	
	⑮기타 필요한 사항	300㎢	2.0	6.0	9.0	12.0	18.0	25.0	
	소 계		17.0	49.0	79.0	125.0	179.0	227.0	
3.성과품 작성	①보고서작성	300㎢	1.0	3.0	5.0	8.0	12.0	15.0	
	②관련 도서작성	300㎢	1.0	3.0	5.0	8.0	12.0	15.0	
	소 계		2.0	6.0	10.0	16.0	24.0	30.0	
총 계			23.0	62.0	101.0	156.0	220.0	279.0	
4.기술협의	①공청회/주민설명회	1식	2.0	2.0	2.0	4.0	4.0	4.0	주2
	②주민간담회/시민계획단	1식	2.0	2.0	2.0	4.0	4.0	4.0	
	③위원회심의 지원	1식	2.0	2.0	2.0	4.0	4.0	4.0	
	④관계기관 협의	1식	2.0	2.0	2.0	4.0	4.0	4.0	
	소 계		8.0	8.0	8.0	16.0	16.0	16.0	

주 : ①항공사진 촬영. 인화 등에 소요되는 비용은 제외

②기술협의는 2회 이내 기준이며, 횟수가 늘어날 경우 증가배수에 해당하는 작업품과 비용을 가산한다. (필요항목 선택적 적용)

③각종영향성검토 및 각종영향평가업무는 별도의 엔지니어링활동업무로 계상한다.

7-6 주요업무내용

구 분	업무내용	내 용
1.관련사항검토	①관련법규 검토	·관리계획수립에 필요한 관계법규 검토
	②관련계획 검토	·관리계획수립에 필요한 상위 및 관련계획검토
	③주변지역과의 상관성 검토	·당해 지역과 주변지역 관련사항 검토
2.관리계획수립	①관리목표와 기본방향	·관련사항 검토결과와 지역여건을 감안하여 합리적인 목표와 기본방향을 설정제시
	②현황 및 실태조사	·인구. 경제. 사회. 문화. 환경 등 전반적인 현황과 실태를 조사하여 관리계획수립에 기초자료로 활용
	③토지이용 및 보전	·토지이용실태. 변화여건. 추세분석 그리고 보전방안을 검토제시
	④도시·군계획시설 설치	·도시·군계획시설의 설치현황분석과 추가설치방안을 검토제시
	⑤대규모의 건축 및 토지 형질변경	·일정규모이상의 건축물의 건축 및 토지의 형질변경사항에 대해 조사분석하고, 이로 인한 문제점과 대처방안을 검토제시
	⑥취락지구 정비	·취락지구의 지정 및 정비방안을 검토제시
	⑦주민지원사업	·주민의 생활편익과 복지증진 등을 위한 다각적인 지원사업방안을 검토제시
	⑧재원조달 및 운용	·개발제한구역의 관리 및 주민지원사업 등에 필요한 재원조달 및 운용방안을 검토제시
	⑨개발제한구역 해제 대상지역의 관리	·광역도시계획, 도시·군기본계획의 기본방향 하에서 구체적인 관리방안 제시
	⑩환경정비	·방치된 폐기물 수거, 훼손된 환경의 복구 방안 등 제시
	⑪축산단지 배치	·축산농가의 집단화 방안 및 배치 등 제시
	⑫구역관리의 전산화	·관리대장 및 도면의 전산화 방안
	⑬위법행위의 지도, 단속, 항공사진 촬영	
	⑭경계표석의 설치 ·관리	·경계표석의 수 및 일련번호 부여
	⑮기타 필요한 사항	·기타 필요사항

7-7 표준성과품

성과구분	표준성과도서			비 고
	구 분	규 격	제출부수	
관리계획 보고서	도 면	발주자와 협의	발주자와 협의	발주자와 협의
	조 서	〃	〃	〃

주 : ①제출부수 및 성과품 종류가 증가할 경우에는 증가배수에 해당하는 작업품과 비용을 가산한다.
②계획보고서 및 기타 관련자료의 규격 및 제출부수는 발주자와의 협의에 의하여 비용을 산정한다.

제8절 도시계획 기초조사

8-1 정 의

○ 도시계획 기초조사는 계획대상지만이 갖고 있는 특성을 파악하고 그 계획대상지에 대한 보다 정확한 진단과 이해를 얻고자 하는 데 의의가 있으며, 계획대상지가 차지하는 위치와 역할에 대한 이해 및 현안의 도출, 계획대상지의 발전과정과 현재의 모든 기능의 파악 및 이해, 당면과제의 파악 및 원인과 해결방안 모색, 자료의 시계열적 분석과 장래변화 예측 등 도시계획의 수립을 위한 목적으로 수행되는 각종 현황자료의 조사·구축을 말한다.

○ 현황자료의 조사는 직접조사와 간접조사로 구분되며, 직접조사란 계획의 대상이 되는 당해지역에 대한 관찰·측정·면접·설문 등을 통하여 시행하는 것이며, 간접조사란 정보를 담고 있는 기존의 여러 가지 서적·정기간행물·도면·문서·각종 통계자료 등을 통하여 시행하는 방법이다.

8-2 자료제공의 전제

○ 당해 과업 중 간접조사에 필요한 모든 관련 자료는 원칙적으로 발주자가 제공하는 것으로 한다.

○ 발주자가 제공하지 못하는 자료의 조사에 있어서는 그 규모·내용에 의거하여 별도의 엔지니어링사업대가를 산정, 직접조사방식으로 엔지니어링사업자가 수행하며, 당해 관련 자료의 기밀성과 광범위한 자료가 요구될 경우에는 조사·분석에 필요한 상당기간과 자료수집비용이 전제되어야 한다.

8-3 업무범위와 추진과정

8-3-1 업무범위

○ 도시계획 기초조사는 계획의 충실도 제고 및 운영관리의 효율성을 높이기 위한 대상지의 자연적·사회적·경제적 조사와 계획상 필요한 형태 및 시설의 조사, 도시경영의 조사·정리를 업무범위로 한다.

8-3-2 추진과정

기초조사추진과정

8-4 품 산정의 원단위 산정과 기준

8-4-1 표준품 산정내역

○ 표준품 산정의 기준이 되는 비목은 제1장 총칙에서 제시한 비목을 중심으로 하였으며, 이는 도시계획 기초조사에 필요한 사항만을 대상으로 한다.

○ 표준품 산정 기준이 되는 직접인건비품의 작업항목별 보할은 기존의 경험적 내용항목별 업무의 난이도를 감안하여 설정토록 한다.

종 별		내 용	세부항목	단 위	비 고
직접비	직접인건비	1.조사·분석	①인문환경 ②자연환경 ③토지이용 ④건축 관련 ⑤인구 및 산업 ⑥교통시설 ⑦유통 및 공급시설 ⑧공간시설 ⑨재정	인·일 〃 〃 〃 〃 〃 〃 〃 〃	간접조사 〃 〃 〃 〃 〃 〃 〃 〃
		2.성과품 작성	①보고서 작성 ②관련 도서작성	〃 〃	〃 〃
	직접경비	여비, 인쇄비, 조감도, 회의준비비, 현장 운영비 등		식	제1장 총칙참조
간접비	제경비	(직접인건비) × 120%		〃	〃
	기술료	(직접인건비+제경비) × 20%		〃	〃

8-4-2 산정 기준

1. 계획·기준인구(면적)의 설정

○ 기준면적은 도시계획관련 각종 계획대상지의 규모분포를 분석하여 설정하며, 직능별 직접인력 소요원단위는 기 작성된 계획 등의 투입기술자 비율을 감안하여 설정한다.

2. 표준품의 산정방법

○ 표준품의 적용에 있어 기준면적·인구와 과업면적·인구의 차이에 따른 품 산정은 아래의 수정식에 따라 기준면적의 소요작업량을 수정하여 산정한다.

○ 소요작업량=기준면적(인구)소요작업량×면적(인구)보정계수(α)×시가화밀도보정계수(β)

3. 계획안의 수정과 과업중지에 따른 품 산정방법

○ 기초조사 결과의 성과물이 작성되고, 관련계획이 주민공람, 의회보고 등 행정절차과정을 거치는 과정에서 발주자의 사정에 의하여 성과물의 일부변경·재작업이 수행되는 경우에는 그 변경·재작업의 정도에 따라 엔지니어링사업대가의 50～100% 수준에서 비용을 추가 지급하여야 한다.

○ 과업수행 중 발주자의 사정에 따라 과업이 중단된 상태에서 정부 회계연도가 경과되어 현저한 비용의 차이가 발생하였을 경우에는 엔지니어링사업대가를 당해 신년도의 노임단가를 기준으로 재산정하여야 한다.

8-4-3 단위별 변화수정과 보정

1. 작업량 보정계수 산정

1) 과업면적·인구의 대소에 대한 작업량 보정계수 산정

○ 도시·군관리계획 수립을 위한 기초조사 : 계획인구가 기준인구를 초과하거나 못 미치는 경우 직접인력 소요작업량의 산정을 위한 보정계수(α)는 다음의 식에 의해 산정한다.

$$\alpha = \left(\frac{\text{계획인구}}{\text{기준인구}}\right)^{0.6} = \left(\frac{A}{5}\right)^{0.6}$$

α = 인구보정계수
A = 계획인구(만인)

계획단위 인구별 보정계수

계획인구(만인)	보정계수 (α)	계획인구(만인)	보정계수 (α)
1	0.381	20	2.297
3	0.736	30	2.930
5	1.000	50	3.981
10	1.516	100	6.034
15	1.933	200	9.146

주 : 계획인구가 1만인 미만인 경우에는 계획인구 1만인을 기준으로 하여 산정한다.

○ 기타 계획수립을 위한 기초조사 : 과업면적이 기준 면적을 초과하거나 이에 못 미치는 경우의 직접인력 소요작업량의 산정을 위한 각 작업내용별 면적보정계수(α)는 다음과 같이 산정한다.

$$\alpha = [\frac{\text{계획면적}}{\text{기준면적}}]^{0.6} = (\frac{A}{10})^{0.6}$$

α = 면적보정계수
A = 계획면적(만㎡)

계획단위 면적별 보정계수

계획면적(만㎡)	보정계수(α)	계획면적(만㎡)	보정계수(α)
3	0.485	50	2.627
5	0.660	70	3.214
10	1.000	80	3.482
20	1.516	90	3.737
30	1.933	100	3.981

주 : 계획면적이 3만㎡ 미만인 경우에는 계획면적 3만㎡를 기준으로 하여 산정한다.

2) 시가화에 따른 밀도보정계수 산정

시가화에 따른 밀도보정계수

구 분	밀도보정계수(β)
1.신시가지(지구단위계획구역) 계획적 개발지로 현재 조성중인 지역 및 미개발지역	0.90
2.시가화 지역 주로 계획적인 개발지로 현재 시가화가 진행중인 지역, 토지구획 정리사업 및 일단의 단지조성사업 등으로 조성된 지역	1.00
3.기성시가지역 역사적으로 개발시기가 오래된 지역으로 대부분 개발이 완료되거나 필지가 세분화된 지역, 주로 시의 중심지역이거나 주요간선변에 면한 지역	1.25

주 : 1개의 계획구역에 특성이 다른 지역이 2개 이상 포함될 때에는 각 지역의 특성에 따른 보정계수로 구분 산정한다.

2. 직접인건비 소요 작업량 산정

○ 계획인구 및 과업면적의 대소에 따른 직접인력 소요작업량의 산정방법은 아래와 같이 기준인구의 직능별 직접인력 소요작업량에 계획단위면적의 보정계수(α)를 곱하여 산출한다.

구 분	기 준	총작업량(인·일)					
		기술사	특 급	고 급	중 급	초 급	보조원
도시·군관리계획 기초조사	5만인	13.3αβ	21.5αβ	69.2αβ	92.2αβ	105.0αβ	110.3αβ
기타계획 기초조사	10만㎡	23.3αβ	39.5αβ	109.2αβ	182.2αβ	340.0αβ	414.3αβ

8-5 표준단위 업무분류와 원단위

1. 도시·군관리계획을 위한 기초조사

기술업무의 직능별 직접인력 소요작업량 (인구 5만인 기준)

(단위 : 인 · 일/표준단위)

구 분	업무내용	표준단위	소요인력						비고
			기술사	특 급	고 급	중 급	초 급	보조원	
1.조사분석	①인문환경	5만인	0.9	1.4	3.4	4.0	3.8	4.3	
	②자연환경	5만인	0.9	1.4	3.4	3.0	3.8	2.8	
	③토지이용	5만인	1.6	2.8	3.4	10.0	10.1	11.4	
	④건축 관련	5만인	1.6	2.8	10.2	10.0	10.1	11.4	
	⑤인구 및 산업	5만인	0.9	1.4	10.2	6.0	6.3	7.1	
	⑥교통시설	5만인	0.9	1.4	3.4	8.0	8.8	7.1	
	⑦유통 및 공급시설	5만인	0.9	1.4	6.8	3.0	6.3	7.1	
	⑧공간시설	5만인	0.9	1.4	3.4	3.0	5.6	4.3	
	⑨재정	5만인	0.9	1.4	3.4	3.0	5.6	4.3	
	⑩GIS 구축	5만인	3.5	5.6	20.4	40.0	40.6	46.2	주1
	소 계		13.0	21.0	68.0	90.0	101.0	106.0	
2.성과품작성	①보고서 작성	5만인	0.2	0.3	0.8	1.5	1.6	1.7	
	②관련 도서작성	5만인	0.1	0.2	0.4	0.7	2.4	2.6	
	소 계		0.3	0.5	1.2	2.2	4.0	4.3	
총 계			13.3	21.5	69.2	92.2	105.0	110.3	

주 : ①GIS 구축은 발주자 측에서 지형 및 지적 Data를 제공한 상태에서, 각종 조사 자료를 GIS로 구축할 경우 적용한다. 지형 및 지형 Data를 제공하지 못할 경우에는 측량 품을 별도 적용하며, 관리를 위한 프로그램 및 컴퓨터 등 장비비는 별도이다.

②본 기초조사는 발주자가 모든 관련 자료를 제공하는 간접조사방식에 의한 조사이며, 관련 자료를 제공하지 못하는 경우 기초자료 수집내용에 따른 별도 엔지니어링사업대가로 산정한다.

③주민의식조사를 위한 설문조사는 직접경비로 별도 계상한다

④각종 공문서 열람 수수료 별도

2. 기타 계획을 위한 기초조사

기술업무의 직능별 직접인력 소요작업량(10만㎡)

(단위 : 인·일/표준단위)

구 분	업무내용	표준 단위	소요인력						비고
			기술사	특 급	고 급	중 급	초 급	보조원	
1.조사분석	①인문환경	10만㎡	2.0	3.0	6.0	12.0	18.0	18.0	
	②자연환경	10만㎡	2.0	3.0	12.0	9.0	18.0	12.0	
	③토지이용	10만㎡	3.0	6.0	18.0	30.0	48.0	75.0	
	④건축 관련	10만㎡	3.0	6.0	18.0	30.0	48.0	74.0	
	⑤인구 및 산업	10만㎡	2.0	3.0	6.0	18.0	30.0	30.0	
	⑥교통시설	10만㎡	2.0	3.0	12.0	24.0	42.0	60.0	
	⑦유통 및 공급시설	10만㎡	2.0	3.0	6.0	9.0	30.0	30.0	
	⑧공간시설	10만㎡	2.0	3.0	6.0	9.0	27.0	18.0	
	⑨재정	10만㎡	2.0	3.0	6.0	9.0	27.0	18.0	
	⑩GIS 구축	10만㎡	3.0	6.0	18.0	30.0	48.0	75.0	주1
	소 계		23.0	39.0	108.0	180.0	336.0	410.0	
2.성과품작성	①보고서 작성	10만㎡	0.2	0.3	0.8	1.5	1.6	1.7	
	②관련 도서작성	10만㎡	0.1	0.2	0.4	0.7	2.4	2.6	
	소 계		0.3	0.5	1.2	2.2	4.0	4.3	
총 계			23.3	39.5	109.2	182.2	340.0	414.3	

주 : ①GIS 구축은 발주자 측에서 지형 및 지적 Data를 제공한 상태에서, 각종 조사 자료를 GIS로 구축할 경우 적용한다. 지형 및 지형 Data를 제공하지 못할 경우에는 측량 품을 별도 적용하며, 관리를 위한 프로그램 및 컴퓨터 등 장비비는 별도이다.

②본 기초조사는 발주자가 모든 관련 자료를 제공하는 간접조사방식에 의한 조사이며, 관련 자료를 제공하지 못하는 경우 기초자료 수집내용에 따른 별도 엔지니어링사업대가로 산정한다.

③주민의식조사를 위한 설문조사는 직접경비로 별도 계상한다

④각종 공문서 열람 수수료 별도

8-6 주요업무내용

구 분	업무내용	내 용
1.조사·분석	①인문환경	·상위계획 및 관련계획, 행정 ·문화재·역사, 문화, 지방의 자원, 향토성 등
	②자연환경	·지형(표고, 경사도), 지질, 지하수, 식생, 토양, 수리, 수질, 기상, 재해(풍수해, 지진) 등 생태, 동식물 서식지 등
	③토지이용	·용도별이용, 토지의 소유, 지가 등에 관한 자료, 지목별, 시가화 동향, 재해위험요소, 농업진흥구역, 임상 등
	④건축 관련	·필지별 건축단위 GIS구축내용, 주요 개발사업 등
	⑤인구 및 산업	·인구총수, 주야간인구, 연령별 인구, 직업별 인구, 산업별 인구, 취업자별 인구, 생활권별 인구, 인구이동 현황 등
	⑥교통시설	·교통시설(도로, 철도, 항만, 공항, 버스터미널 등), 교통량(단면교통량, 기종점교통량, 사람통행, 물자유통량 등)
	⑦유통 및 공급시설	·상수도, 하수도, 전기·통신, 가스공급시설 등 ·교육문화시설, 의료(병원수, 병상수), 복지시설, 행정관리시설 등
	⑧공간시설	·공원(위치, 면적, 종별) 등에 관한 자료, 임상이 양호한 산림(보전임지, 공익임지), 농업진흥구역의 면적·분포 등에 관한 사항 등 ·대기오염, 소음, 진동, 일조, 수질오염, 악취, 토양오염, 폐기물의 종류별 발생현황과 처리시설, 폐수의 발생량 및 처리시설, 생태계 등
	⑨재정	·재정자립도, 지방세수입액, 재산세, 지방채발행, 도시계획세, 교부금 등
	⑩GIS구축	·Data 입력 및 정리

8-7 표준성과품

성과구분	표준성과도서			비 고
	구 분	규 격	제출부수	
현황도	· 토지이용현황도 · 도시·군계획시설현황도 · 지형(표고)현황도 · 주요시설현황도 · 인구밀도분포현황도	1/25,000이상 1/25,000이상 1/25,000이상 1/25,000이상 1/25,000이상	1부 1부 1부 1부 1부	
보고서	· 도시·군관리계획(재정비) 입안기초조사보고서		1부	
C D	· 자료 CD		기준단위	

주 : ①제출부수 및 성과품 종류가 증가할 경우에는 증가배수에 해당하는 작업품과 비용을 가산한다.
②계획보고서 및 기타 관련자료의 규격 및 제출부수는 발주자와의 협의에 의하여 비용을 산정한다.

제9절 성장관리방안

9-1 정 의

○ 성장관리방안은 개발압력이 높은 지역 등에 대하여 기반시설의 설치 · 변경, 건축물의 용도 등에 관한 기본방향을 미리 설정함으로써 당해 지역의 계획적 개발을 유도해 나가고자 하는 방안으로 도시·군기본계획 및 도시·군관리계획의 내용에 부합하도록 수립하여 비시가화지역의 난개발을 방지하고 계획적 개발 및 관리를 유도하는 정책이다.

9-2 자료제공의 전제

○ 당해 계획의 수립에 필요한 모든 관련자료는 원칙적으로 발주자가 제공하는 것으로 하되, 발주자가 보유하지 않는 자료는 엔지니어링사업자가 조사·수집한다.

○ 발주자가 제공하지 못하는 자료의 조사(교통량조사, 건물조사, 수목 및 산림조사, 도시시설물조사 등)에 있어서는 그 규모·내용에 의거하여 별도의 엔지니어링사업대가를 산정하여 엔지니어링사업자가 수행하며, 당해 관련자료의 기밀성과 광범위한 자료가 요구되는 경우 조사·분석에 필요한 상당기간과 자료수집비용이 전제되어야 한다.

9-3 업무범위와 추진과정

9-3-1 업무범위

○ 성장관리방안의 업무범위는 현황조사 및 여건분석, 기본구상, 부문별 기본방향, 성과품 작성 등을 주 업무범위로 하며,

○ 성장관리방안의 수립목적 달성을 위해 “성장관리방안 수립지침”에서 제시하고 있는 부문별 내용이 포함되는 계획을 수립하여야 한다. 다만, 성장관리방안의 목적달성을 위해 반드시 필요한 경우 계획내용의 상세정도에 차등을 둘 수 있다.

9-3-2 추진과정

○ 타부처(관계기관)와의 협의나 전문가 자문 등에 소요되는 기간은 과업수행기간에서 제외하여 그 소요기간 만큼 과업수행기간을 연장하여야 한다.

1. 계획수립추진과정

기초조사

↓

성장관리방안 입안

↓

주민 · 지방의회 의견청취

↓

관계기관 협의

↓

시 · 군 도시계획위원회 심의

↓

성장관리방안 결정 및 고시

↓

일반열람

2. 과업수행추진과정

성장관리방안의 목적

↓

여 건 분 석 — ·기초조사

↓

기 본 구 상 — ·기본방향
·토지이용체계구상
·교통동선체계구상

↓

부문별 기본방향 — ·용도지역·지구
·교통처리
·공원녹지
·도시기반시설
·가구 및 획지규모와 조성
·건축물규모에 관한 계획
·건축물 형태, 색채 등에 관한 계획
·경관계획
·환경관리계획

↓

성 과 품 작 성

9-4 품 산정의 원단위 산정과 기준

9-4-1 표준품 산정내역

○ 표준품 산정의 기준이 되는 비목은 제1장 총칙에서 제시한 비목을 중심으로 하였으며, 이는 성장관리방안에 필요한 사항만을 대상으로 한다.

○ 표준품 산정의 기준이 되는 직접인건비 품의 작업항목별 보할은 기존의 경험적 내용 및 항목별 업무의 난이도를 감안하여 설정토록 한다.

1. 성장관리지역 설정

종 별		내 용	세부항목	단 위	비 고
직접비	직접인건비	1.기초조사	①기초조사	인·일	
		2.개발여건 분석	①개발가용지 분석 ②개발압력 분석 ③지가변동 분석 ④인구증가 분석 ⑤관련계획 분석	〃 〃 〃 〃 〃	
		3.성장관리 지역지정	①평가지표 설정 ②현장조사 ③성장관리지역 지정(안)작성	〃 〃 〃	
		4.성과품 작성	①보고서작성 및 편집 ②관련도서작성	〃 〃	
		5.기술협의	①공청회/주민설명회 ②주민간담회/시민계획단 ③위원회심의 지원 ④관계기관 협의	〃 〃 〃 〃	
	직접경비	여비, 인쇄비, 조감도, 회의준비비, 현장 운영비 등		식	제1장 총칙참조
간접비	제경비	(직접인건비) × 120%		〃	〃
	기술료	(직접인건비+제경비) × 25%		〃	〃

주 : 성장관리지역 설정과 성장관리방안을 동시에 추진할 경우 각 품을 합산하여 적용한다.

2. 성장관리방안 수립

종 별		내 용	세부항목	단 위	비 고
직접비	직접인건비	1.현황조사 및 여건분석	①자연환경	인·일	
			②인구 및 산업현황	〃	
			③토지소유 및 이용현황	〃	
			④건축물현황	〃	
			⑤교통현황	〃	
			⑥도시기반시설현황	〃	
			⑦도시계획현황 및 관련계획	〃	
			⑧현황자료분석	〃	
		2.기본구상	①기본방향	〃	
			②토지이용체계구상	〃	
			③교통동선체계구상	〃	
		3.부문별 기본방향	①용도지역·지구	〃	
			②교통처리	〃	
			③공원녹지	〃	
			④도시기반시설	〃	
			⑤가구 및 획지규모와 조성	〃	
			⑥건축물규모에 관한 계획	〃	
			⑦건축물 형태・색채 등에 관한 계획	〃	
			⑧경관계획	〃	
			⑨환경보전계획	〃	
		4.성과품 작성	①보고서작성 및 편집	〃	
			②관련도서작성	〃	
		5.기술협의	①공청회/주민설명회	〃	
			②주민간담회/시민계획단	〃	
			③위원회심의 지원	〃	
			④관계기관 협의	〃	
	직접경비	여비, 인쇄비, 조감도, 회의준비비, 현장 운영비 등		식	제1장 총칙참조
간접비	제경비	(직접인건비) × 120%		〃	〃
	기술료	(직접인건비+제경비) × 25%		〃	〃

주 : 성장관리방안 수립품은 개당 산정 후 최종금액을 합하여 산정하도록 한다.

9-4-2 산정 기준

1. 계획・기준면적의 설정

○ 성장관리지역 설정의 기준면적은 전국의 시 · 군 면적분포를 분석하여 10㎢로 산정 하였으며, 계획대상지면적이 3㎢에 미달할 때에는 3㎢를 계획면적으로 적용한다.

○ 성장관리방안의 계획면적 산정은 성장관리지역으로 지정된 면적을 기준으로 한다.

○ 성장관리방안은 성장관리지역으로 지정된 부지를 계획대상지로 하며 기준면적은 3만㎡를 원칙으로 한다.

2. 표준품의 산정방법

○ 표준품의 적용에 있어 기준면적과 계획면적의 차이에 따른 품 산정은 아래의 수정식에 따라 기준인구의 소요작업량을 수정하여 산정한다.

○ 소요작업량 = 기준면적 × 면적보정계수(α)

3. 계획안의 수정과 과업중지에 따른 품 산정방법

○ 계획안이 작성되고 주민공람, 의회보고 등 행정절차과정을 거쳐 계획안이 확정된 후 발주자의 사정에 의하여 계획안이 일부변경·재작업이 수행되는 경우에는 그 변경·재작업의 정도에 따라 엔지니어링사업대가의 50～100% 수준에서 비용을 추가 지급하여야 한다.

○ 과업수행 중 발주자의 사정에 따른 과업 중단으로 인해 정부 회계연도가 경과되어 현저한 비용의 차이가 발생하였을 경우에는 엔지니어링사업대가를 당해 신년도의 노임단가를 기준으로 재산정하여야 한다.

9-4-3 단위별 변화수정과 보정

1. 작업량 보정계수 산정

1) 성장관리지역 설정 면적의 대소에 대한 작업량 보정계수 산정

○ 계획면적이 기준면적을 초과하거나 이에 못 미치는 경우의 직접인력 소요작업량의 산정을 위한 각 작업내용별 보정계수(α)는 다음과 같이 산정한다.

$$\alpha = \left(\frac{\text{계획면적}}{\text{기준면적}}\right)^{0.5} = \left(\frac{A}{10}\right)^{0.5}$$

α = 보정계수
A = 계획면적(㎢)

계획면적에 대한 작업량 보정계수

계획면적(㎢)	보정계수(α)	계획면적(㎢)	보정계수(α)
3	0.548	40	2.000
5	0.707	70	2.646
10	1.000	100	3.162
20	1.414	150	3.873
30	1.732	200	4.472

주 : 계획면적이 3㎢ 미만인 경우에는 계획면적 3㎢를 기준으로 하여 산정한다.

2) 성장관리방안 수립 면적의 대소에 대한 작업량 보정계수 산정

○ 계획면적이 기준면적을 초과하거나 이에 못 미치는 경우의 직접인력 소요작업량의 산정을 위한 각 작업내용별 보정계수(α)는 다음과 같이 산정한다.

$$\alpha = (\frac{\text{계획면적}}{\text{기준면적}})^{0.6} = (\frac{A}{3})^{0.6}$$

α = 보정계수
A = 계획면적(만㎡)

계획면적에 대한 작업량 보정계수

계획면적(만㎡)	보정계수(α)	계획면적(만㎡)	보정계수(α)
3	1.000	50.0	5.409
5	1.359	70.0	6.619
10	2.059	100.0	8.198
20	3.121	150.0	10.456
30	3.981	200.0	12.426

주 : 계획면적이 3만㎡ 미만인 경우에는 계획면적 3만㎡를 기준으로 하여 산정한다.

2. 직접인건비 소요 작업량 산정

○ 계획면적의 대소에 따른 직접인력 소요작업량의 산정방법은 아래와 같이 기준면적의 직능별 직접인력 소요작업량에 계획단위 보정계수(α)를 곱하여 산출한다.

구 분	기준면적	총작업량(인·일)					
		기술사	특 급	고 급	중 급	초 급	보조원
성장관리지역 설정	10(㎢)	6.7α	10.5α	28.6α	38.7α	61.6α	76.7α
성장관리방안 수립	3(만㎡)	20.8α	33.8α	82.7α	109.3α	216.2α	265.2α

9-5 표준단위 업무분류와 원단위

1. 성장관리지역 설정

기술업무의 직능별 직접인력 소요작업량 (면적10㎢ 기준)

(단위 : 인 · 일/표준단위)

구 분	업무내용	표준단위	소요인력						비고
			기술사	특 급	고 급	중 급	초 급	보조원	
1.기초조사	①기초조사	10㎢	1.1	1.8	5.8	7.8	8.6	9.2	주1
2.개발여건 분석	①개발가용지 분석 ②개발압력 분석 ③지가변동 분석 ④인구증가 분석 ⑤관련계획 분석	10㎢ 10㎢ 10㎢ 10㎢ 10㎢	0.6 0.6 0.6 0.6 0.6	0.8 0.8 0.8 0.8 0.8	3.0 3.0 2.0 2.0 2.0	3.0 3.0 3.0 3.0 2.0	7.0 6.0 6.0 6.0 6.0	8.0 8.0 8.0 8.0 8.0	
	소 계		3.0	4.0	12.0	14.0	31.0	40.0	
3.성장관리 지역지정	①평가지표 설정 ②현장조사 ③성장관리지역 지정(안)작성	10㎢ 10㎢ 10㎢	0.4 0.2 0.8	0.8 0.6 1.5	2.0 1.6 3.0	2.5 2.4 5.0	4.0 3.0 6.0	8.0 3.0 4.0	
	소 계		1.4	2.9	6.6	9.9	13.0	15.0	
4.성과품 작 성	①보고서작성 및 편집 ②관련도서작성	10㎢ 10㎢	0.6 0.6	0.6 1.2	1.2 3.0	2.0 5.0	3.0 6.0	4.5 8.0	
	소 계		1.2	1.8	4.2	7.0	9.0	12.5	
총 계			6.7	10.5	28.6	38.7	61.6	76.7	
5.기술협의	①공청회/주민설명회 ②주민간담회/시민계획단 ③위원회심의 지원 ④관계기관 협의	1식 1식 1식 1식	2.0 2.0 2.0 2.0	2.0 2.0 2.0 2.0	2.0 2.0 2.0 2.0	4.0 4.0 4.0 4.0	4.0 4.0 4.0 4.0	4.0 4.0 4.0 4.0	주2
	소 계		8.0	8.0	8.0	16.0	16.0	16.0	

주 : ①기초자료는 "9-2 자료제공의 전제"에 의거 발주자가 제공하여야 하며, 제공하지 못하는 자료에 대하여는 제8절의 도시계획 기초조사의 품을 참조하여 별도 산정한다.

②기술협의는 2회 이내 기준이며, 횟수가 늘어날 경우 증가배수에 해당하는 작업품과 비용을 가산한다. (필요항목 선택적 적용)

③기초조사는 도시·군기본계획 및 도시·군관리계획 수립시 구축된 자료를 활용할 경우 기초조사의 품을 제외할 수 있다.

④성장관리지역 설정과 성장관리방안을 단일 건으로 종합하여 발주할 경우 각 품을 합산하여 산정한다.

2. 성장관리방안 수립

기술업무의 직능별 직접인력 소요작업량(면적3만㎡ 기준)

(단위 : 인 · 일/표준단위)

구 분	업무내용	표준단위	소요인력						비고
			기술사	특 급	고 급	중 급	초 급	보조원	
1.현황조사 및 여건분석	①자연환경	3만㎡	0.3	0.6	1.4	2.3	3.1	4.7	주1
	②인구 및 산업현황	3만㎡	0.3	0.6	1.4	3.5	5.6	5.8	
	③토지소유 및 이용현황	3만㎡	0.6	1.2	2.8	6.9	8.6	10.8	
	④건축물현황	3만㎡	0.5	1.2	2.8	7.5	8.7	10.5	
	⑤교통현황	3만㎡	0.3	0.6	1.4	4.2	5.7	8.0	
	⑥도시기반시설현황	3만㎡	0.3	0.6	1.0	2.5	3.4	5.8	
	⑦도시계획현황 및 관련계획	3만㎡	0.3	0.6	1.0	2.8	4.2	4.4	
	⑧현황자료분석	3만㎡	0.3	0.6	1.4	2.3	3.1	-	
	소 계		2.9	6.0	13.2	32.0	42.4	50.0	
2.기본구상	①기본방향	3만㎡	0.5	0.8	2.7	2.3	5.3	7.1	
	②토지이용체계구상	3만㎡	0.5	0.9	2.7	2.3	5.3	7.1	
	③교통동선체계구상	3만㎡	0.2	0.5	2.3	2.0	4.4	7.1	
	소 계		1.2	2.2	7.7	6.6	15.0	21.3	
3.부문별 기본방향	①용도지역·지구	3만㎡	1.5	2.3	5.8	3.1	18.4	20.8	
	②교통처리	3만㎡	2.2	3.3	7.7	6.7	17.8	30.3	
	③공원녹지	3만㎡	0.7	1.1	3.5	3.1	5.8	10.1	
	④도시기반시설	3만㎡	2.7	3.8	11.6	13.7	25.6	25.6	
	⑤가구 및 획지규모와 조성	3만㎡	1.1	1.7	4.2	4.1	14.3	16.4	
	⑥건축물규모에 관한 계획	3만㎡	2.2	3.0	6.6	8.5	17.5	19.7	
	⑦건축물 형태·색채 등에 관한 계획	3만㎡	3.3	4.6	10.0	12.8	26.3	29.5	
	⑧경관 계획	3만㎡	1.5	2.2	4.2	3.5	11.9	20.2	주2
	⑨환경관리계획	3만㎡	-	-	-	-	-	-	주3
	소 계		15.2	22.0	53.6	55.5	137.6	172.6	
4.성과품 작성	①보고서작성 및 편집	3만㎡	1.2	2.4	5.4	9.1	9.1	6.1	
	②관련도서작성	3만㎡	0.3	1.2	2.8	6.1	12.1	15.2	
	소 계		1.5	3.6	8.2	15.2	21.2	21.3	
총 계			20.8	33.8	82.7	109.3	216.2	265.2	
5.기술협의	①공청회/주민설명회	1식	2.0	2.0	2.0	4.0	4.0	4.0	주4
	②주민간담회/시민계획단	1식	2.0	2.0	2.0	4.0	4.0	4.0	
	③위원회심의 지원	1식	2.0	2.0	2.0	4.0	4.0	4.0	
	④관계기관 협의	1식	2.0	2.0	2.0	4.0	4.0	4.0	
	소 계		8.0	8.0	8.0	16.0	16.0	16.0	

주 : ①기초자료는 "9-2 자료제공의 전제"에 의거 발주자가 제공하여야 하며, 제공하지 못하는 자료에 대하여는 제8절의 도시계획 기초조사의 품을 참조하여 별도 산정한다.

②지구경관계획 필요시 제7장 제2절 지구경관계획의 엔지니어링품을 별도 적용한다.

③환경관리계획은 과업의 특성에 따라 별도 환경영향평가의 품을 고려하여 비용을 가산한다.

④기술협의는 2회 이내 기준이며, 횟수가 늘어날 경우 증가배수에 해당하는 작업품과 비용을 가산한다. (필요항목 선택적 적용)

⑤복수의 성장관리방안 수립은 개소당 산정 후 최종금액을 합산하여 산정한다.

9-6 주요업무내용

1. 성장관리지역 설정

구 분	업무내용	내 용
1.기초조사	①기초조사	·도시・군기본계획 수립지침에 규정된 조사방법을 준용
2.개발여건 분석	①개발가용지 분석	·도시・군기본계획 수립지침에 규정된 분석방법을 준용
	②개발압력 분석	·개발행위허가의 입지 및 패턴분석
	③지가변동 분석	·통계자료를 이용한 지가변동률 분석
	④인구증가 분석	·통계자료를 이용한 인구증가율 분석
	⑤관련계획 분석	·상위 및 관련계획 검토
3.성장관리 지역지정	①평가지표 설정	·비시가화지역의 발전방향 ·인구 및 가구에 관한 지표설정 ·토지용도 및 생활환경지표의 설정
	②현장조사	·자연환경, 인문환경 등 조사
	③성장관리지역 지정(안)작성	·설정목적 및 각종 지표와 계획의 효과 ·문제점 분석 및 부문별계획의 수립과정

2. 성장관리방안 수립

구 분	업무내용	내 용
1.현황조사 및 분석	①자연환경	·지형, 지세, 기상, 수계 등 조사
	②인구 및 산업현황	·상주인구, 가구규모, 취업인구 등 인구 및 산업관련 현황 조사
	③토지소유 및 이용현황	·토지의 소유, 지목, 이용상태 등 조사
	④건축물현황	·건축물의 용도, 층수, 구조, 용적률, 배치, 형태, 색채 등 건물현황 조사
	⑤교통현황	·도로, 차량, 보행자, 교통시설 등 교통관련현황 조사
	⑥도시기반시설현황	·의료, 보건, 사회복지, 교육, 문화, 체육시설, 공원·녹지 등 ·구역내외의 상수도, 하수도, 에너지공급 등 공급처리시설 현황조사
	⑦도시계획현황 및 관련계획	·용도지역·지구·구역, 도시·군계획시설 현황, 기타 상위 및 관련계획 검토
	⑧현황자료분석	·가로시설물·조경 등
2.기본구상	①기본방향	·도시계획 및 설계의 제어요소 등 법적사항 검토 포함
	②토지이용체계구상	·공간구성체계설정 ·토지이용구상안 작성
	③교통동선체계구상	·이용자의 이용체계구상 ·토지이용에 따른 기능별 교통동선체계 구상

구 분	업무내용		내 용
3. 부 문 별 계획	①용도지역·지구	◦세부토지이용	·도시계획의 내용을 구체화한 대상구역의 토지이용계획
		◦용도지역·지구 세분	
	②교통처리	◦교통분석 및 동선	·대상구역 및 주변지역의 차량 및 보행자에 대한 교통처리계획 및 시설계획 ·교통량예측 및 배분 포함
		◦교통시설	
		◦교통처리	
		◦교통시설의 배치와 규모계획	
	③공원녹지	◦공원·녹지	·대상구역 및 주변지역의 공원녹지시설계획 - 생태도시 조성방향 포함
		◦공원·녹지시설의 배치와 규모계획	
	④도시기반시설	◦공급처리시설 용량 예측	·상수도 및 하수도, 전기 · 통신계획 및 에너지(Gas등)소요량 예측
		◦에너지 등 자원의 절약 및 재활용계획	·지역에 적합한 에너지 등 자원에 대한 절약 및 재활용 계획 및 조정계획
		◦생활환경시설계획	·지역에 적합한 생활환경시설에 대한 계획 및 조정계획
		◦기타 도시기반 시설 계획	·지역에 적합한 도시기반시설에 대한 계획 및 조정계획
		◦도시기반시설의 배치와 규모계획	·각종 도시기반시설에 대한 규모 및 배치계획 및 조정계획
	⑤가구 및 획지 규모와 조성	◦가구 및 획지 계획	·기존 대지규모 및 용도지역·지구에 적합한 가구 및 획지규모에 대한 계획 및 조성계획
		◦가구 및 획지 조성 계획	
	⑥건축물 규모·형태·색채 등에 관한 계획	◦건축물 용도	·가구 및 획지조정계획에 따른 건축물 및 시설배치, 용도, 밀도, 높이, 형태, 색채 및 건축선에 대한 계획
		◦건축물 밀도	
		◦건축물 높이	
		◦건축물 배치 및 건축선	
		◦건축물의 형태 및 색채	
		◦기 타	·공동개발 및 합벽건축, 대지안의 공지, 공개공지 등
	⑦ 경관계획	◦도시경관구조 분석	·건축물의 색채와 외부환경에 대한 계획 ·도시내 주요간선도로 등 도시의 경관축을 이루는 가로변의 건축물이나 수목, 조형물에 대한 조성지침 ·보행자를 위한 가로환경 및 가로시설물에 대한 계획
		◦도시축별 경관계획	
		◦건축물 외관계획	
		◦색채계획	
		◦기타 역사 · 문화 경관계획 등	
	⑧ 환경보전계획		·환경보전 및 관리계획 ·재해방지계획

9-7 표준성과품

성과구분	표준성과도서			비 고
	구 분	규 격	제출부수	
현황도	·주변구역 현황도 ·토지이용 현황도 ·건축물 현황도 ·도시계획 현황도		1부 〃 〃 〃	-토지이용, 기타관련사항 -토지이용현황 -용도, 구조, 층수 -용도지역지구, 도시·군계획시설
계획도	·성장관리지역총괄도	1/25,000 ~ 1/50,000	1부	
	·성장관리지역설정도	1/3,000 ~ 1/6,000	1부	-토지이용체계, 교통체계
	·기반시설의 배치와 규모에 관한 성장관리지역 설정도		〃	-도시계획도로 및 세가로의 배치, 차량 및 보행자 동선 처리계획, 주차장 등
	·건축물에 대한 용도·건폐율·용적률·높이·배치·형태·색채 등에 관한 성장관리지역 설정도		〃	-용도, 건폐율, 용적률, 높이, 배치, 형태, 색채 등
보고서	·성장관리방안 설명서	발주자와 협의결정	발주자와 협의결정	

주 : ①제출부수 및 성과품 종류가 증가할 경우에는 증가배수에 해당하는 작업품과 비용을 가산한다.
②계획보고서 및 기타 관련자료의 규격 및 제출부수는 발주자와의 협의에 의하여 비용을 산정한다.

제10절 개발행위허가

10-1 정 의

○ 개발행위허가는 개발과 보전이 조화되게 유도하여 국토관리의 지속가능성을 제고시키고, 토지에 대한 정당한 재산권 행사를 보장하여 토지의 경제적 이용과 환경적 보전의 조화를 도모하며, 계획의 적정성, 기반시설의 확보여부, 주변 경관 및 환경과의 조화 등을 고려하여 허가여부를 결정함으로써 난개발을 방지하고 국토의 계획적 관리를 도모하는 제도이다.

10-2 자료제공의 전제

○ 개발행위허가 수립에 필요한 모든 관련자료는 원칙적으로 발주자가 제공하는 것으로 하되, 발주자가 보유하지 않는 자료는 엔지니어링사업자가 조사·수집한다.

○ 발주자가 제공하지 못하는 자료의 조사에 있어서는 그 규모·내용에 의거하여 별도의 엔지니어링사업대가를 산정하여 엔지니어링사업자가 수행하며, 당해 관련자료의 기밀성과 광범위한 자료가 요구되는 경우 조사·분석에 필요한 상당기간과 자료수집비용이 전제되어야 한다.

10-3 업무범위와 추진과정

10-3-1 업무범위

○ 개발행위허가는 상위계획 및 주변 여건을 검토하여 공사의 개요, 개발행위의 내용, 기반시설계획, 기타계획, 예산내역서 등을 수립하여 계획도면과 계획조서 및 기타 참고도서 등을 작성한다.

10-3-2 추진과정

○ 타부처(관계기관)와 협의나 전문가 자문 등에 소요되는 기간은 과업수행기간에서 제외하여 그 소요기간만큼 과업수행기간을 연장하여야 한다.

1. 계획수립추진과정

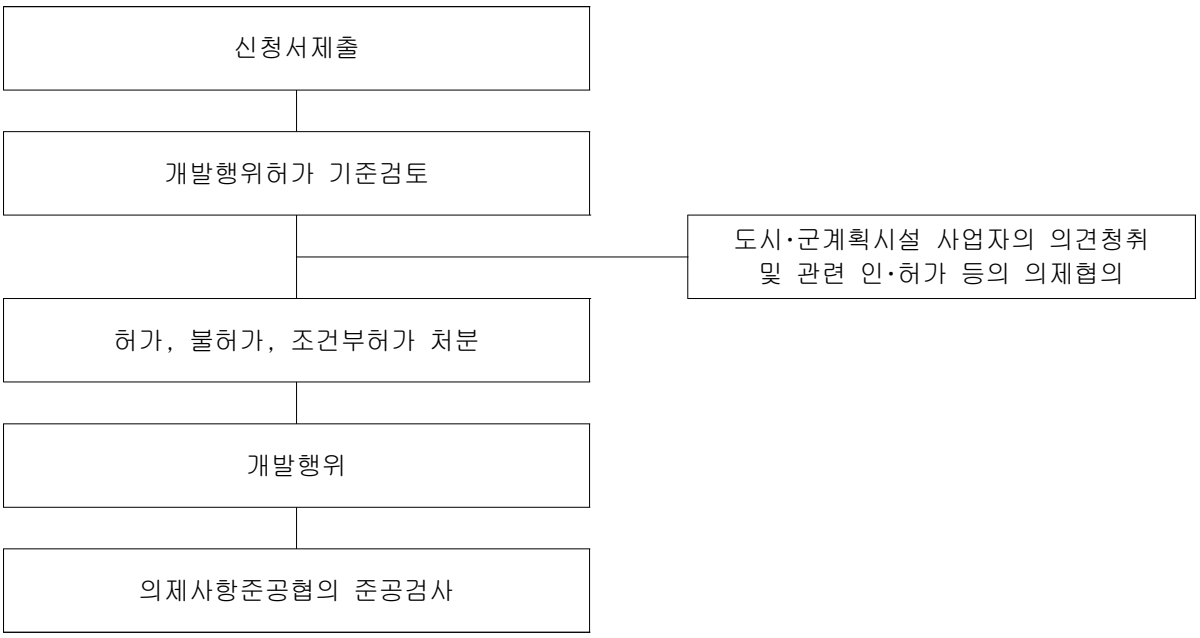

2. 과업수행추진과정

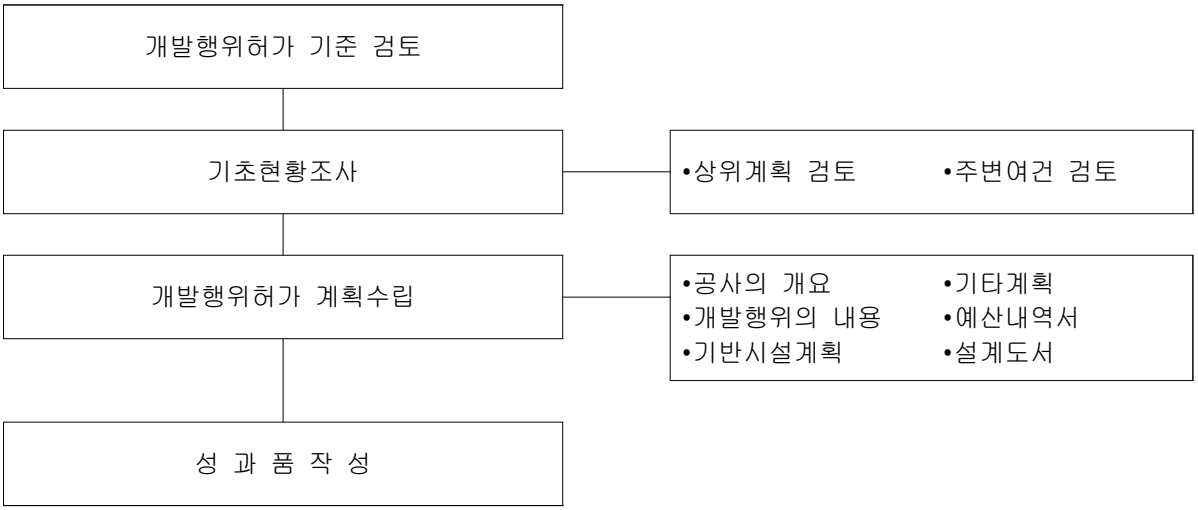

10-4 품 산정의 원단위 산정과 기준

10-4-1 표준품 산정내역

○ 표준품 산정의 기준이 되는 비목은 제1장 총칙에서 제시한 비목을 중심으로 하였으며, 이는 개발행위허가수립에 필요한 사항만을 대상으로 한다.

○ 표준품 산정의 기준이 되는 직접인건비 품의 작업항목별 보할은 기존의 경험적 내용 및 항목별 업무의 난이도를 감안하여 설정토록 한다.

종 별		내 용	세부항목	단 위	비 고
직접비	직접인건비	1.개발계획 검토	①관련법규 검토 ②관련계획 검토 ③주변지역과의 영향성 검토	인·일 〃 〃	
		2.개발행위 신청 도서 작성	①개발행위허가 신청서 작성 ②편입토지조서 작성 ③사업계획서 작성 ④건축물 계획 ⑤피해방지 계획서 작성 ⑥경사분석 ⑦진입도로/교통처리 계획 ⑧대체기반시설 계획 ⑨개발행위허가 기준 검토 ⑩경관체크리스트 검토 ⑪예산 내역서 ⑫협의의견 및 조치결과 작성 ⑬의제협의도서 작성	〃 〃 〃 〃 〃 〃 〃 〃 〃 〃 〃 〃 〃	
		3.성과품작성	①관련도서 작성	〃	
		4.기술협의	①공청회/주민설명회 ②주민간담회/시민계획단 ③위원회심의 지원 ④관계기관 협의	〃 〃 〃 〃	
	직접경비	여비, 인쇄비, 조감도, 회의준비비, 현장운영비 등		식	제1장 총칙참조
간접비	제경비	(직접인건비) × 120%		〃	〃
	기술료	(직접인건비+제경비) × 25%		〃	〃

10-4-2 산정기준

1. 계획·기준면적의 설정

○ 사업의 조사설계 산정의 원단위 기준을 마련하기 위하여 기준면적은 3만㎡로 하였으며, 직능별 직접인력 소요원단위는 기 작성되었던 관련계획 등의 투입기술자 비율을 감안하여 설정하였다.

○ 계획면적은 당해 개발행위허가의 과업면적을 원칙으로 한다.

2. 표준품의 산정방법

○ 표준품의 적용에 있어 계획면적이 0.1만㎡이하의 경우에는 0.1만㎡를 적용하며, 기준면적이 0.1만㎡이상의 경우일 때는 아래의 수정식에 따라 대상 업무별로 단위별 변화조정과 보정에 의하여 산정토록 한다.

○ 소요작업량 = 기준면적 소요작업량 × 면적보정계수(α)

3. 계획안의 수정과 과업중지에 따른 품 산정방법

○ 계획안이 작성되고 주민공람, 의회보고 등 행정절차과정을 거쳐 계획안이 확정된 후 발주자의 사정에 의하여 계획안이 일부변경·재작업이 수행되는 경우에는 그 변경·재작업의 정도에 따라 엔지니어링사업대가의 50～100% 수준에서 비용을 추가 지급하여야 한다.

○ 과업수행 중 발주자의 사정에 따른 과업 중단으로 인해 정부 회계연도가 경과되어 현저한 비용의 차이가 발생하였을 경우에는 엔지니어링사업대가를 당해 신년도의 노임단가를 기준으로 재산정하여야 한다.

10-4-3 단위별 변화수정과 보정

1. 면적의 대소에 대한 작업량 보정계수 산정

○ 계획면적이 기준면적을 초과하거나 못 미치는 경우의 직접인력 소요작업량의 산정을 위한 면적보정계수(α)는 다음의 식에 의해 산정한다.

$$\alpha = \left(\frac{\text{계획면적}}{\text{기준면적}}\right)^{0.5} = \left(\frac{A}{3}\right)^{0.5}$$

α = 보정계수
A = 계획면적(만㎡)

계획단위면적별 보정계수

계획면적(만㎡)	보정계수(α)	계획면적(만㎡)	보정계수(α)
0.1	0.183	4.0	1.155
0.5	0.408	5.0	1.291
1.0	0.577	10.0	1.826
2.0	0.816	20.0	2.582
3.0	1.000	50.0	4.082

주 : 계획면적이 0.1만㎡ 미만인 경우에는 계획면적 0.1만㎡를 기준으로 하여 산정한다.

2. 직접인건비 소요 작업량 산정

○ 개발행위허가 직접인력 소요작업량의 산정방법은 아래와 같이 기준면적의 직능별 직접인력 소요작업량에 계획단위면적의 보정계수(α)를 곱하여 산출한다.

구 분	기준면적 (만㎡)	총작업량(인·일)					
		기술사	특 급	고 급	중 급	초 급	보조원
개발행위허가	3	2.2α	7.7α	18.1α	22.3α	44.4α	49.9α

10-5 표준단위 업무분류와 원단위

기술업무의 직능별 직접인력 소요작업량(면적 3만㎡ 기준)

(단위 : 인·일/표준단위)

구 분	업무내용	표준단위	소요인력						비고
			기술사	특 급	고 급	중 급	초 급	보조원	
1.개발계획 검토	①관련법규 검토	3만㎡	-	0.1	0.1	0.1	0.2	0.2	
	②관련계획 검토	3만㎡	-	0.1	0.1	0.1	0.2	0.2	
	③주변지역과의 영향성 검토	3만㎡	-	0.1	0.1	0.1	0.2	0.2	
	소 계		-	0.3	0.3	0.3	0.6	0.6	
2.개발행위 신청도서 작성	①개발행위허가 신청서 작성	3만㎡	-	0.1	0.1	0.1	0.2	0.2	
	②편입토지조서 작성	3만㎡	-	1.2	2.3	2.9	5.8	8.2	
	③사업계획서 작성	3만㎡	0.6	1.0	5.8	6.8	14.5	11.6	
	④건축물 계획	3만㎡	-	0.1	0.1	0.1	0.2	0.2	
	⑤피해방지 계획서 작성	3만㎡	-	0.1	0.1	0.1	0.2	0.2	
	⑥경사분석	3만㎡	0.2	0.8	2.1	2.7	6.3	6.1	
	⑦진입도로/교통처리계획	3만㎡	0.8	0.8	1.1	1.1	1.2	1.1	
	⑧대체기반시설 계획	3만㎡	-	2.3	4.6	5.8	11.6	16.4	
	⑨개발행위허가 기준 검토	3만㎡	-	0.1	0.1	0.1	0.2	0.2	
	⑩경관체크리스트 검토	3만㎡	-	0.1	0.1	0.1	0.2	0.2	
	⑪예산 내역서	3만㎡	-	-	-	-	-	-	
	⑫협의의견 및 조치결과 작성	3만㎡	0.6	0.6	1.2	2.0	3.0	4.5	
	⑬의제협의도서 작성	3만㎡	-	-	-	-	-	-	
	소 계		2.2	7.2	17.6	21.8	43.4	48.9	
3.성과품 작성	①관련도서 작성	3만㎡	-	0.2	0.2	0.2	0.4	0.4	
	소 계		-	0.2	0.2	0.2	0.4	0.4	
총 계			2.2	7.7	18.1	22.3	44.4	49.9	
4.기술협의	①공청회/주민설명회	1식	2.0	2.0	2.0	4.0	4.0	4.0	
	②주민간담회/시민계획단	1식	2.0	2.0	2.0	4.0	4.0	4.0	
	③위원회심의 지원	1식	2.0	2.0	2.0	4.0	4.0	4.0	
	④관계기관 협의	1식	2.0	2.0	2.0	4.0	4.0	4.0	
	소 계		8.0	8.0	8.0	16.0	16.0	16.0	

주 : ①기술협의는 2회 이내 기준이며, 횟수가 늘어날 경우 증가배수에 해당하는 작업품과 비용을 가산한다. (필요항목 선택적 적용)

②각종영향성검토 및 각종영향평가업무는 별도의 엔지니어링활동업무로 계상한다.

③토목설계, 건축설계는 별도의 엔지니어링활동업무로 계상한다.

10-6 주요업무내용

구 분	내 용	
1.개발계획검토	·상위관련계획 분석 및 이용상황 검토 ·편입토지 및 지장물 현황조사·분석	·개발행위내용 설정 ·구상안 작성
2.개발행위신청도서 작성	·사업의 개요 ·사업계획(건축개요 포함) ·사업시행계획	·부지조성설계도서 검토 ·건축설계도서 검토 ·예산내역서 검토

10-7 표준성과품

성과구분	표준성과도서			비 고
	구 분	규 격	제출부수	
현황도	주변관계및현황분석도 현황종합분석도 기본구상도	1/5,000~1/1,000 1/5,000~1/1,000 1/5,000~1/500	1부 〃 〃	위치, 자연환경, 토지이용, 기존계획, 교통주요시설 등
계획도	종합기본계획도 토지이용계획도 교통동선계획도 시설물배치계획도 식재계획도 공급처리시설계획도	1/5,000~1/500 〃 〃 〃 〃 〃	〃 〃 〃 〃 〃 〃	
보고서	계획보고서 예산내역서	발주자와 협의결정	발주자와 협의결정	관리운영계획, 사업계획 포함

주 : ①제출부수 및 성과품 종류가 증가할 경우에는 증가배수에 해당하는 작업품과 비용을 가산한다.
②계획보고서 및 기타 관련자료의 규격 및 제출부수는 발주자와의 협의에 의하여 비용을 산정한다.

제11절 도시방재계획

11-1 정 의

○ 「도시방재계획」이란 도시방재에 관한 계획으로서 도시계획 수립시 반드시 필요한 기본적인 계획으로서, 여러 계획 속에서 도시방재가 중요한 목표가 되거나 계획 수립시 도시방재에 대처하도록 하는 별도의 계획이다.

○ 도시방재계획은 도시·군기본계획도서와 별책 보고서로 작성하는 도시방재계획(수립보고서)이다.

○ 본 품의 도시방재계획은 기존 광역도시계획, 도시 · 군기본계획, 도시 · 군관리계획 상의 부문별계획에 포함되는 ‘방재분야’의 「방재계획」과는 구별된다.

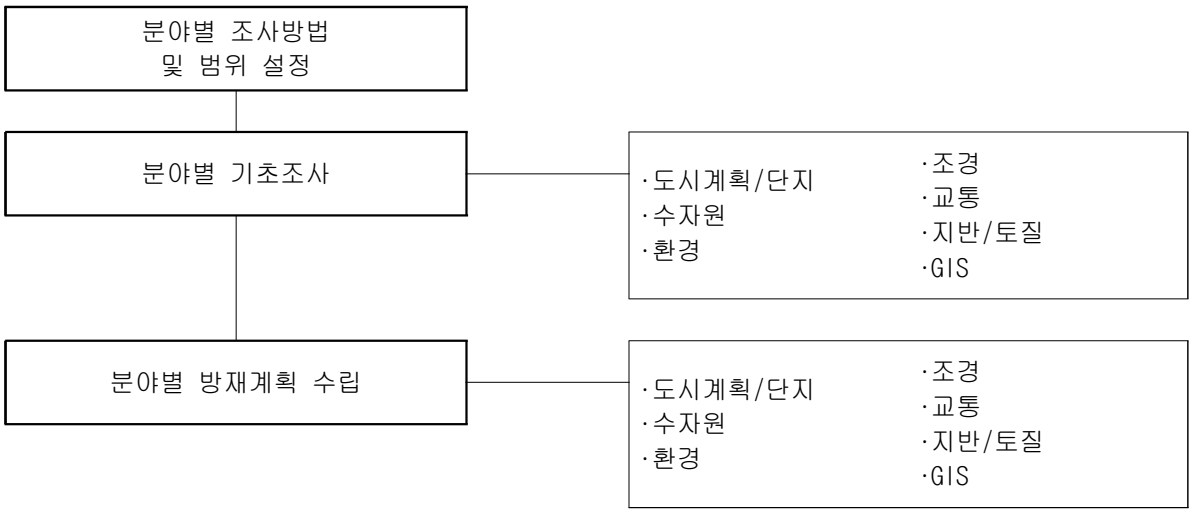

11-2 자료제공의 전제

○ 당해 계획의 수립에 필요한 모든 관련자료는 원칙적으로 발주자가 제공하는 것으로 하되, 발주자가 보유하지 않는 자료는 엔지니어링사업자가 조사·수집한다.

○ 발주자가 제공하지 못하는 자료의 조사에 있어서는 그 규모·내용에 의거하여 별도의 엔지니어링사업대가를 산정하여 엔지니어링사업자가 수행하며, 당해 관련자료의 기밀성과 광범위한 자료가 요구되는 경우 조사·분석에 필요한 상당기간과 자료수집비용이 전제되어야 한다.

11-3 업무범위와 추진과정

11-3-1 업무범위

○ 도시방재계획의 업무범위는 분야별 현황조사, 방재계획 수립, 성과품 작성 등을 주 업무범위로 하며,

○ 도시방재계획의 수립목적 달성을 위해 도시에서 발생가능한 각 분야별 방재요소를 조사하고 이를 반영한 효율적인 도시방재계획을 수립하여야 한다.

11-3-2 추진과정

○ 타부처(관계기관)와의 협의나 전문가 자문 등에 소요되는 기간은 과업수행기간에서 제외하여 그 소요기간 만큼 과업수행기간을 연장하여야 한다.

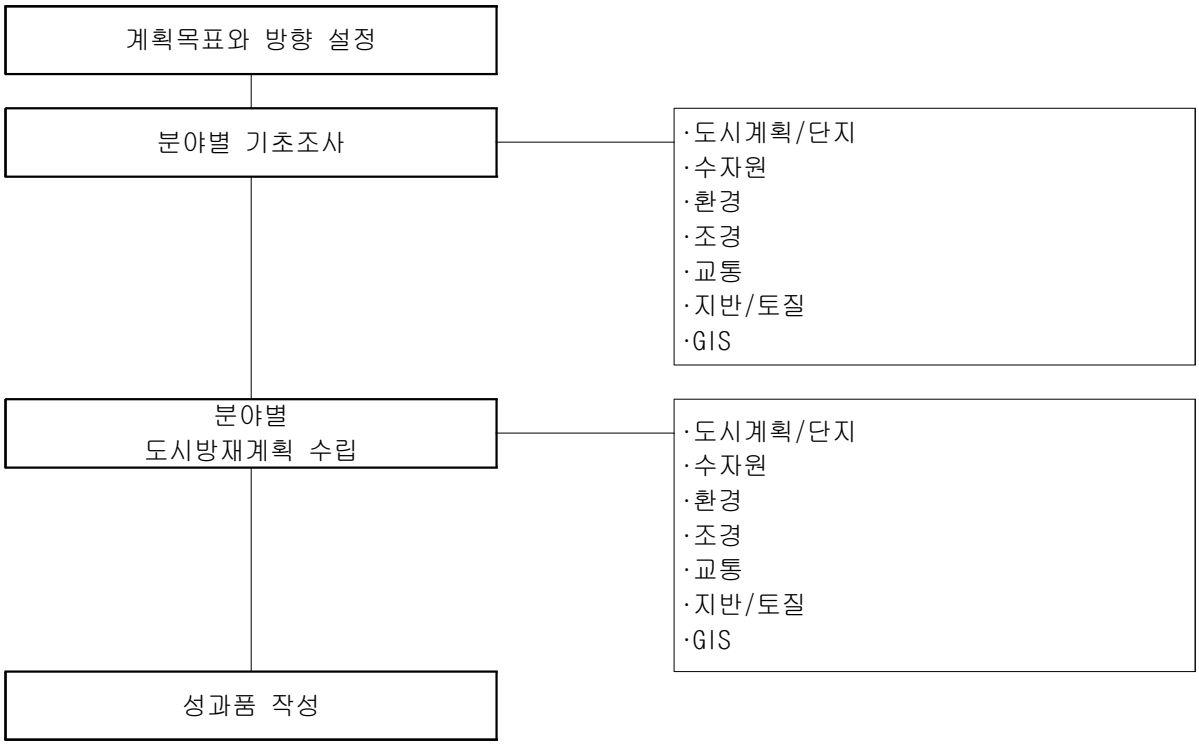

11-4 품 산정의 원단위 산정과 기준

11-4-1 표준품 산정내역

○ 표준품 산정의 기준이 되는 비목은 제1장 총칙에서 제시한 비목을 중심으로 하였으며, 이는 도시방재계획수립에 필요한 사항만을 대상으로 한다.

○ 표준품 산정의 기준이 되는 직접인건비 품의 작업항목별 보할은 기존의 경험적 내용 및 항목별 업무의 난이도를 감안하여 설정토록 한다.

종 별		내 용	세부항목	단 위	비 고
직접비	직접인건비	1.분야별 기초조사	①도시계획 ②단지 ③수자원 ④환경 ⑤조경 ⑥교통 ⑦지반/토질 ⑧GIS	인·일 〃 〃 〃 〃 〃 〃 〃	
		2.분야별 방재계획수립	①도시계획 ②단지 ③수자원 ④환경 ⑤조경 ⑥교통 ⑦지반/토질 ⑧GIS	〃 〃 〃 〃 〃 〃 〃 〃	
		3.성과품 작성	①보고서작성 및 편집 ②관련도서작성	〃 〃	
		4.기술협의	①공청회/주민설명회 ②주민간담회/시민계획단 ③위원회심의 지원 ④관계기관 협의	〃 〃 〃 〃	
	직접경비	여비, 인쇄비, 조감도, 회의준비비, 현장 운영비 등		식	제1장 총칙참조
간접비	제경비	(직접인건비)×120%		〃	〃
	기술료	(직접인건비+제경비) ×20%		〃	〃

11-4-2 산정 기준

1. 계획인구의 설정

○ 도시방재계획 수립을 위한 인구는 전국적으로 대상이 되는 시의 인구분포를 분석하여 인구 10만인으로 설정하며, 직능별 직접인력 소요원단위는 기 작성된 도시방재계획 등의 투입기술자 비율을 감안하여 설정한다.

○ 계획인구는 당해 도시권의 목표인구를 원칙으로 한다.

2. 표준품의 산정방법

○ 표준품의 적용에 있어 기준인구와 계획인구의 차이에 따른 품 산정은 아래의 수정식에 따라 기준인구의 소요작업량을 수정하여 산정한다.

○ 소요작업량 = 기준인구 소요작업량 × 인구보정계수(α)

3. 계획안의 수정과 과업중지에 따른 품 산정방법

○ 계획안이 작성되고 주민공람, 의회보고 등 행정절차과정을 거쳐 계획안이 확정된 후 발주자의 사정에 의하여 계획안이 일부변경·재작업이 수행되는 경우에는 그 변경·재작업의 정도에 따라 엔지니어링사업대가의 50~100% 수준에서 비용을 추가 지급하여야 한다.

○ 과업수행 중 발주자의 사정에 따른 과업 중단으로 인해 정부 회계연도가 경과되어 현저한 비용의 차이가 발생하였을 경우에는 엔지니어링사업대가를 당해 신년도의 노임단가를 기준으로 재산정하여야 한다.

11-4-3 단위별 변화수정과 보정

1. 인구(면적)의 대소에 대한 작업량 보정계수 산정

○ 목표연도 인구는 계획인구로 한다.

○ 도시의 계획인구가 기준인구를 초과하거나 이에 못 미치는 경우의 직접인력 소요작업량의 산정을 위한 각 작업내용별 보정계수(α)는 다음과 같이 산정한다.

$$\alpha = (\frac{\text{계획인구}}{\text{기준인구}})^{0.5} = (\frac{A}{10})^{0.5}$$

α = 보정계수
A = 계획인구(만인)

계획면적에 대한 작업량 보정계수

계획인구(만인)	보정계수(α)	계획인구(만인)	보정계수(α)
10	1.000	100	3.162
20	1.414	150	3.873
30	1.732	200	4.472
50	2.236	400	6.325
70	2.646	500	7.071

주 : 계획인구가 10만인 미만인 경우에는 계획인구 10만인을 기준으로 하여 산정한다.

2. 직접인건비 소요 작업량 산정

○ 계획면적의 대소에 따른 직접인력 소요작업량의 산정방법은 아래와 같이 기준면적의 직능별 직접인력 소요작업량에 계획단위 보정계수(α)를 곱하여 산출한다.

구 분	기준인구 (만인)	총작업량 (인·일)					
		기술사	특 급	고 급	중 급	초 급	보조원
도시방재계획	10	37.7α	61.2α	189.9α	277.6α	382.8α	409.6α

11-5 표준단위 업무분류와 원단위

기술업무의 직능별 직접인력 소요작업량 (인구10만인 기준)

(단위 : 인 · 일/표준단위)

구 분	업무내용	표준단위	소요인력						비고
			기술사	특 급	고 급	중 급	초 급	보조원	
1.기초조사	①도시계획	10만인	3.0	6.0	18.0	30.0	48.0	75.0	주1
	②단지	10만인	2.0	3.0	12.0	9.0	18.0	12.0	
	③수자원	10만인	2.0	3.0	12.0	9.0	18.0	12.0	
	④환경	10만인	2.0	3.0	12.0	9.0	18.0	12.0	
	⑤조경	10만인	2.0	3.0	12.0	9.0	18.0	12.0	
	⑥교통	10만인	2.0	3.0	12.0	9.0	18.0	12.0	
	⑦지반/토질	10만인	2.0	3.0	12.0	9.0	18.0	12.0	
	⑧GIS	10만인	2.0	3.0	12.0	9.0	18.0	12.0	
	소 계		17.0	27.0	102.0	93.0	174.0	159.0	
2.분야별 방재계획 수립	①도시계획	10만인	4.9	8.1	17.5	51.0	46.2	50.9	
	②단지	10만인	1.7	2.7	7.1	14.6	15.5	17.6	
	③수자원	10만인	2.3	3.6	9.9	18.7	22.1	21.8	
	④환경	10만인	1.7	2.7	7.1	14.6	15.5	17.6	
	⑤조경	10만인	1.7	2.7	7.1	14.6	15.5	17.6	
	⑥교통	10만인	1.7	2.7	7.1	14.5	15.5	17.5	
	⑦지반/토질	10만인	1.7	2.7	7.1	14.6	15.5	17.6	
	⑧GIS	10만인	3.0	6.0	18.0	30.0	48.0	75.0	
	소 계		18.7	31.2	80.9	172.6	193.8	235.6	
3.성과품 작성	①보고서작성 및 편집	10만인	1.0	1.5	3.5	6.0	7.5	7.5	
	②관련도서작성	10만인	1.0	1.5	3.5	6.0	7.5	7.5	
	소 계		2.0	3.0	7.0	12.0	15.0	15.0	
합 계			37.7	61.2	189.9	277.6	382.8	409.6	
4.기술협의	①공청회/주민설명회	1식	2.0	2.0	2.0	4.0	4.0	4.0	주2
	②주민간담회/시민계획단	1식	2.0	2.0	2.0	4.0	4.0	4.0	
	③위원회심의 지원	1식	2.0	2.0	2.0	4.0	4.0	4.0	
	④관계기관 협의	1식	2.0	2.0	2.0	4.0	4.0	4.0	
	소 계		8.0	8.0	8.0	16.0	16.0	16.0	

주 : ①기초자료는 "11-2 자료제공의 전제"에 의거 발주자가 제공하여야 하며, 제공하지 못하는 자료에 대하여는 제11장 제8절의 도시계획 기초조사의 품을 참조하여 별도 산정한다.

②기술협의는 2회 이내 기준이며, 횟수가 늘어날 경우 증가배수에 해당하는 작업품과 비용을 가산한다. (필요항목 선택적 적용)

11-6 주요업무내용

구 분	업무내용	내 용
1.분야별 기초조사	①도시계획	·지형지세, 수문수계, 기상기후 등 자연환경 ·재난피해현황, 재난관련 공공시설물 등 도시기반시설 현황 ·상위 및 관련계획, 도시·군관리계획, 각종개발사업, 관련법규 검토 등
	②단지	·재난관련 단지 및 구조물, 개발행위허가 현황 ·붕괴위험지역, 급경사지
	③수자원	·수계별 유출량 조사로 수해예상지역 조사 ·저류지 및 빗물펌프장 등 수해관련시설 조사
	④환경	·비오톱, 비점오염원. 토질오염, 온실가스, 도시열섬 등 수질 및 대기환경조사
	⑤조경	·공원녹지체계 및 녹지관련시설설치 현황 ·저류가능녹지 및 식생조사 등
	⑥교통	·교통관련계획 및 교통량현황 조사 ·저류 및 녹화 가능한 도로, 주차장 등 교통시설조사
	⑦지반/토질	·산사태위험지역, 경사지 및 붕괴위험지역 조사 등
	⑧GIS	·재해관련시설 3차원 전산화(우수관로 BIM구축)
2.분야별 방재계획수립	①도시계획	·분야별 방재현황조사 및 계획총괄 ·도시방재네트워크 구상 및 방재거점 등 도시안전계획 수립 ·도시, 건축 등 종합적이고 전략적인 도시방재계획안 마련 ·방재지구지정, 중점관리지역지정 등 기술협의
	②단지	·수계분석자료를 근거로 한 자연지형 순응형 단지조성계획 및 방재관련 기반시설계획
	③수자원	·집중호우에 대비한 저류지, 비상우수관망 확보 등 대책수립 ·재해위험지구 등 방재관련 중점 관리지역 계획·
	④환경	·바람길, 미기후, 환경오염 등을 고려한 도시방재계획 수립 ·물순환, 폐기물순환, 에너지순환 등 자원순환형 도시관리방안 마련
	⑤조경	·공원녹지네트워크를 활용한 자연형 도시방재 시스템 구축 ·공원, 녹지 등 오픈스페이스를 활용한 방재거점계획 및 도시열섬방지를 위한 물순환시스템 구축
	⑥교통	·교통수요분석을 통한 도로 폭 축소, 주차장설치 등 저류형 녹지공간 확보 및 안전계획 수립
	⑦지반/토질	·사면안정성 검토 및 연약지반 개선대책 수립 ·재해위험을 고려한 지반 안정대책 수립 및 산사태 위험지역 설정
	⑧GIS	·종합적인 도시방재의 정비 및 지속적 관리시스템 구축 ·시뮬레이션 활용을 통한 방재예방 및 저감계획 수립

11-7 표준성과품

성과구분	표준성과도서			비 고
	구 분	규 격	제출부수	
현황도	·재난피해종합현황도 ·재난피해지역 분포도 ·재난관련시설물설치현황도 ·재난관련 도시·군관리계획도	1/25,000이상 1/25,000이상 1/25,000이상 1/25,000이상	1부 1부 1부 1부	
보고서	·도시방재계획 보고서			발주자와 협의
CD	·자료 및 보고서 CD		1식	

주 : ①제출부수 및 성과품 종류가 증가할 경우에는 증가배수에 해당하는 작업품과 비용을 가산한다.
②계획보고서 및 기타 관련자료의 규격 및 제출부수는 발주자와의 협의에 의하여 비용을 산정한다.

제12절 저탄소 녹색도시계획

12-1 정 의

○ 저탄소 녹색도시계획은 ‘저탄소 녹색도시 조성을 위한 도시계획수립지침’에 따라 도시·군기본계획도서와 별책 보고서로 작성하는 저탄소 녹색도시계획(수립보고서)이다.

○ 본 품의 저탄소 녹색도시계획은 기존 도시·군기본계획 상 계획의 목표와 지표 부분에 포함되는 「저탄소 녹색도시계획방향」과는 구별된다.

○ 저탄소 녹색도시계획은 국가가 수립한 국가기후변화종합기본계획 등과 연계하여 온실가스 배출감축과 흡수를 유도할 수 있도록 도시계획의 방향과 부문별 계획을 수립하는데 지침이 되는 것으로서 광역도시계획, 도시·군기본계획, 도시·군관리계획에 각각 수립된다.

○ 본 품의 기준은 저탄소 녹색도시조성을 위한 도시계획수립지침 중 도시·군기본계획에의 적용부문을 기준으로 한다.

12-2 자료제공의 전제

○ 당해 계획의 수립에 필요한 모든 관련자료는 원칙적으로 발주자가 제공하는 것으로 하되, 발주자가 보유하지 않는 자료는 엔지니어링사업자가 조사·수집한다.

○ 발주자가 제공하지 못하는 자료의 조사에 있어서는 그 규모·내용에 의거하여 별도의 엔지니어링사업대가를 산정하여 엔지니어링사업자가 수행하며, 당해 관련자료의 기밀성과 광범위한 자료가 요구되는 경우 조사·분석에 필요한 상당기간과 자료수집비용이 전제되어야 한다.

12-3 업무범위와 추진과정

12-3-1 업무범위

○ 저탄소 녹색도시계획은 온실가스배출 감축 등 기후변화에 대비하고 저탄소 녹색도시 조성을 위한 종합적인 공간계획수립을 유도하기 위한 것으로서 다음의 업무를 도시의 특성에 맞게 수행한다.

○ 저탄소 녹색도시계획수립을 위한 현황조사 · 분석 및 과제도출

- 온실가스배출현황 파악
- 온실가스 매출 장래예측
- 신재생에너지 확보잠재력 파악

○ 저탄소녹색도시 기본구상

- 온실가스감축 계획기간과 목표설정

○ 부문별 · 권역별 저탄소 녹색도시계획수립

- 부문별 계획
- 권역별 계획

○ 저탄소녹색도시 시행전략수립

- 재원조달방안
- 단계별 추진전략

12-3-2 추진과정

○ 타부처(관계기관)와의 협의나 전문가 자문 등에 소요되는 기간은 과업수행기간에서 제외하여 그 소요기간 만큼 과업수행기간을 연장하여야 한다.

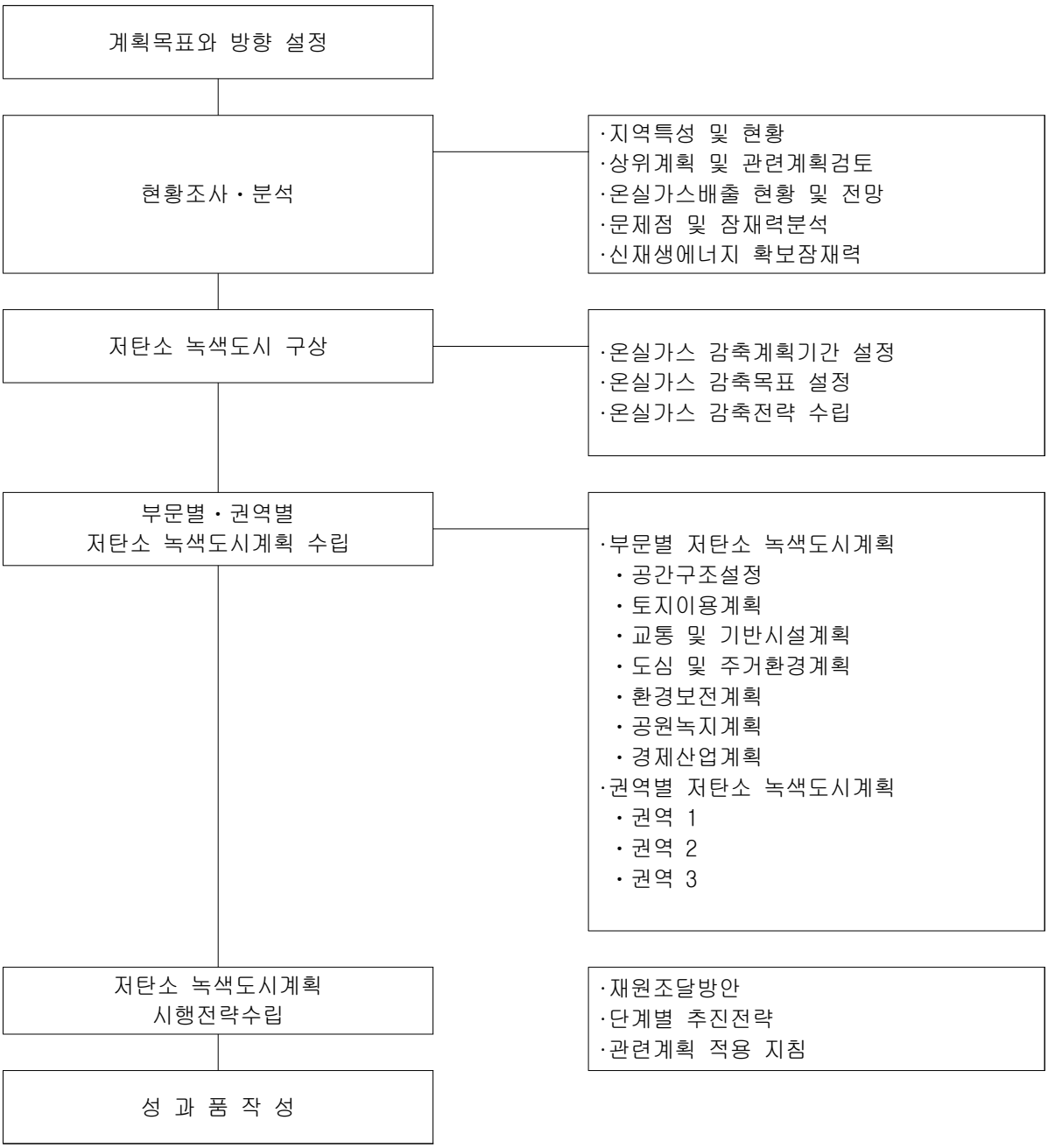

12-4 품 산정의 원단위 산정과 기준

12-4-1 표준품 산정내역

○ 표준품 산정의 기준이 되는 비목은 제1장 총칙에서 제시한 비목을 중심으로 하였으며, 이는 저탄소 녹색도시계획수립에 필요한 사항만을 대상으로 한다.

○ 표준품 산정의 기준이 되는 직접인건비 품의 작업항목별 보할은 기존의 경험적 내용 및 항목별 업무의 난이도를 감안하여 설정토록 한다.

종 별		내 용	세부항목	단 위	비 고
직접비	직접인건비	1.개발여건분석	①현황조사・분석 ②종합분석 및 과제도출	인·일 〃	
		2.기본구상	①저탄소녹색도시 구상	〃	
		3.계획수립	①부문별 저탄소 녹색도시계획 ②권역별 저탄소 녹색도시계획	〃 〃	
		4.시행전략	①저탄소 녹색도시계획 시행전략	〃	
		4.성과품 작성	①보고서작성 및 편집 ②관련도서작성	〃 〃	
		5.기술협의	①공청회/주민설명회 ②주민간담회/시민계획단 ③위원회심의 지원 ④관계기관 협의	〃 〃 〃 〃	
	직접경비	여비, 인쇄비, 조감도, 회의준비비, 현장 운영비 등		식	제1장 총칙참조
간접비	제경비	(직접인건비)×120%		〃	〃
	기술료	(직접인건비+제경비) ×30%		〃	〃

12-4-2 산정 기준

1. 계획인구의 설정

○ 저탄소 녹색도시계획 수립을 위한 인구는 전국적으로 대상이 되는 시의 인구분포를 분석하여 인구 10만인으로 설정하며, 직능별 직접인력 소요원단위는 기 작성된 저탄소 녹색도시계획 등의 투입기술자 비율을 감안하여 설정한다.

○ 계획인구는 당해 도시권의 목표인구를 원칙으로 한다.

2. 표준품의 산정방법

○ 표준품의 적용에 있어 기준인구와 계획인구의 차이에 따른 품 산정은 아래의 수정식에 따라 기준인구의 소요작업량을 수정하여 산정한다.

○ 소요작업량 = 기준인구 소요작업량 × 인구보정계수(α)

3. 계획안의 수정과 과업중지에 따른 품 산정방법

○ 계획안이 작성되고 주민공람, 의회보고 등 행정절차과정을 거쳐 계획안이 확정된 후 발주자의 사정에 의하여 계획안이 일부변경·재작업이 수행되는 경우에는 그 변경·재작업의 정도에 따라 엔지니어링사업대가의 50～100% 수준에서 비용을 추가 지급하여야 한다.

○ 과업수행 중 발주자의 사정에 따른 과업 중단으로 인해 정부 회계연도가 경과되어 현저한 비용의 차이가 발생하였을 경우에는 엔지니어링사업대가를 당해 신년도의 노임단가를 기준으로 재산정하여야 한다.

4. 저탄소 녹색도시계획 이외의 품 산정방법

○ 표준품 산정기준이 책정되지 않은 기타의 저탄소녹색도시 관련계획(신도시계획, 재정비촉진사업 등에서의 저탄소 녹색도시계획)은 저탄소 녹색도시계획 용역대가의 50%~100% 수준에서 산정한다. 단, 각 계획적용은 같은 위계의 계획을 준한다.

12-4-3 단위별 변화수정과 보정

1. 인구(면적)의 대소에 대한 작업량 보정계수 산정

○ 도시의 계획인구가 기준인구를 초과하거나 이에 못 미치는 경우의 직접인력 소요작업량의 산정을 위한 각 작업내용별 보정계수(α)는 다음과 같이 산정한다.

$$\alpha = (\frac{\text{계획인구}}{\text{기준인구}})^{0.5} = (\frac{A}{10})^{0.5}$$

α = 보정계수
A = 계획인구(만인)

계획면적에 대한 작업량 보정계수

계획인구(만인)	보정계수(α)	계획인구(만인)	보정계수(α)
10	1.000	100	3.162
20	1.414	150	3.873
30	1.732	200	4.472
50	2.236	400	6.325
70	2.646	500	7.071

주 : 계획인구가 10만인 미만인 경우에는 계획인구 10만인을 기준으로 하여 산정한다.

2. 직접인건비 소요 작업량 산정

○ 계획면적의 대소에 따른 직접인력 소요작업량의 산정방법은 아래와 같이 기준면적의 직능별 직접인력 소요작업량에 계획단위 보정계수(α)를 곱하여 산출한다.

구 분	기준인구 (만인)	총작업량 (인·일)					
		기술사	특 급	고 급	중 급	초 급	보조원
저탄소 녹색도시계획	10	24.0α	43.0α	98.0α	143.0α	163.0α	181.0α

12-5 표준단위 업무분류와 원단위

기술업무의 직능별 직접인력 소요작업량 (인구10만인 기준)

(단위 : 인 · 일/표준단위)

구 분	업무내용	표준단위	소요인력						비고
			기술사	특 급	고 급	중 급	초 급	보조원	
1. 개발여건 분석	①현황조사・분석	10만인	3.0	4.0	9.0	16.0	21.0	30.0	주1
	②종합분석 및 과제도출	10만인	1.0	2.0	3.0	4.0	6.0	6.0	
	소 계		4.0	6.0	11.0	20.0	27.0	36.0	
2.기본구상	①저탄소녹색도시 구상	10만인	3.0	4.0	6.0	10.0	20.0	30.0	
3.계획수립	①부문별 저탄소녹색도시 계획	10만인	10.0	20.0	50.0	55.0	60.0	60.0	
	②권역별 저탄소녹색도시 계획	10만인	5.0	10.0	20.0	40.0	40.0	40.0	
	소 계		15.0	30.0	70.0	95.0	100.0	100.0	
4.시행전략	①저탄소 녹색도시계획 시행전략	10만인	3.0	4.0	9.0	16.0	21.0	30.0	
5.성과품작성	①보고서작성 및 편집	10만인	1.0	1.5	3.5	6.0	7.5	7.5	
	②관련도서작성	10만인	1.0	1.5	3.5	6.0	7.5	7.5	
	소 계		2.0	3.0	7.0	12.0	15.0	15.0	
합 계			24.0	43.0	98.0	143.0	163.0	181.0	
5.기술협의	①공청회/주민설명회	1식	2.0	2.0	2.0	4.0	4.0	4.0	주2
	②주민간담회/시민계획단	1식	2.0	2.0	2.0	4.0	4.0	4.0	
	③위원회심의 지원	1식	2.0	2.0	2.0	4.0	4.0	4.0	
	④관계기관 협의	1식	2.0	2.0	2.0	4.0	4.0	4.0	
	소 계		8.0	8.0	8.0	16.0	16.0	16.0	

주 : ①현황조사·분석은 도시・군기본계획 및 도시・군관리계획 수립시 구축된 자료를 활용할 경우 기초조사의 품을 제외할 수 있다.

②기술협의는 2회 이내 기준이며, 횟수가 늘어날 경우 증가배수에 해당하는 작업품과 비용을 가산한다. (필요항목 선택적 적용)

③저탄소 녹색도시계획을 광역도시계획, 도시・군기본계획, 도시・군관리계획의 부문별계획으로 수립하는 경우, 저탄소 녹색도시계획의 1내지 5항목은 50%를 적용한다.

④기초자료는 "11-2 자료제공의 전제"에 의거 발주자가 제공하여야 하며, 제공하지 못하는 자료에 대하여는 제8절의 도시계획 기초조사의 품을 참조하여 별도 산정한다.

12-6 주요업무내용

구 분	항 목	내 용
1.개발여건 분석	①현황조사・분석	·온실가스 배출현황 파악 ·온실가스 배출 장래 예측 ·신재생에너지 확보 잠재력 ·상위 및 관련계획
	②종합분석 및 과제도출	·계획여건 종합 ·계획과제 도출
2.기본구상	①저탄소 녹색도시 구상	·온실가스 감축 계획기간 및 목표 설정 ·온실가스 감축 전략 수립
3.계획수립	①부문별 저탄소 녹색도시계획	·저탄소 도시공간구조 설정 ·토지이용계획 ·교통 및 기반시설계획 ·도심 및 주거환경 계획 ·환경보전계획 ·공원녹지계획 ·경제·산업계획
	②권역별 저탄소 녹색도시계획	·권역(생활권 단위)별 기후변화대응 계획
4.시행전략	①저탄소 녹색도시계획 시행전략	·재원조달계획 ·단계별 추진전략 ·관련계획 적용 지침

12-7 표준성과품

성과구분	표준성과도서			비 고
	구 분	규 격	제출부수	
구상도	·권역별 저탄소 녹색도시 구상도	1/25,000 ~ 1/50,000	1부	
보고서	·저탄소 녹색도시계획 보고서			발주자와 협의
CD	·자료 및 보고서 CD		1식	

주 : ①제출부수 및 성과품 종류가 증가할 경우에는 증가배수에 해당하는 작업품과 비용을 가산한다.
②계획보고서 및 기타 관련자료의 규격 및 제출부수는 발주자와의 협의에 의하여 비용을 산정한다.

제4장 도시설계

제1절 지구단위계획

제2절 마을만들기

제1절 지구단위계획

1-1 정 의

○ 지구단위계획은 당해 지구단위계획구역의 토지이용을 합리화하고 그 기능을 증진시키며 경관ㆍ미관을 개선하고 양호한 환경을 확보하며, 당해 구역을 체계적·계획적으로 계획 · 관리하기 위하여 건축물 그 밖의 시설의 용도·종류 및 규모 등에 대한 제한을 완화하거나 건폐율 또는 용적률을 완화하여 수립하는 계획을 말한다.

○ 지구단위계획구역내의 일부지역을 대상으로 토지이용계획과 건축물계획이 서로 환류되도록 함으로써 평면적 토지이용계획과 입체적 시설계획이 서로 조화를 이루도록 하는데 중점을 두며, 난개발 방지를 위하여 개별 개발수요를 집단화하고 기반시설을 충분히 설치함으로써 개발이 예상되는 지역을 체계적으로 개발·관리하기 위한 계획이다.

1-2 자료제공의 전제

○ 당해 계획의 수립에 필요한 지적지형도(1/500-1/3,000)등 모든 관련자료는 원칙적으로 발주자가 제공하는 것으로 하되, 발주자가 보유하지 않는 자료는 엔지니어링사업자가 수집한다.

○ 발주자가 제공하지 못하는 자료의 조사에 있어서는 그 규모·내용에 의거하여 별도의 엔지니어링사업대가를 산정하여 엔지니어링사업자가 수행하며, 관련자료의 기밀성과 광범위한 자료가 필요할 경우 조사·분석에 필요한 상당기간과 자료수집비용이 전제되어야 한다.

1-3 업무범위와 추진과정

1-3-1 업무범위

○ 지구단위계획의 업무범위는 현황조사 및 여건분석, 기본구상, 부문별 계획, 시행계획, 성과품 작성 등을 주 업무범위로 한다.

○ 지구단위계획구역이 사업구역 또는 용도지구 등이 아닌 기성시가지에 지정되어있고, 도시·군계획시설의 배치와 규모, 가구 및 획지의 규모와 조성계획 등이 필요한 경우에는 기본설계, 실시설계 등을 포함한다.

1-3-2 추진과정

○ 타부처(관계기관)와 협의나 전문가 자문 등에 소요되는 기간은 과업수행기간에서 제외하여 그 소요기간 만큼 과업수행기간을 연장하여야 한다.

1. 계획수립 추진과정

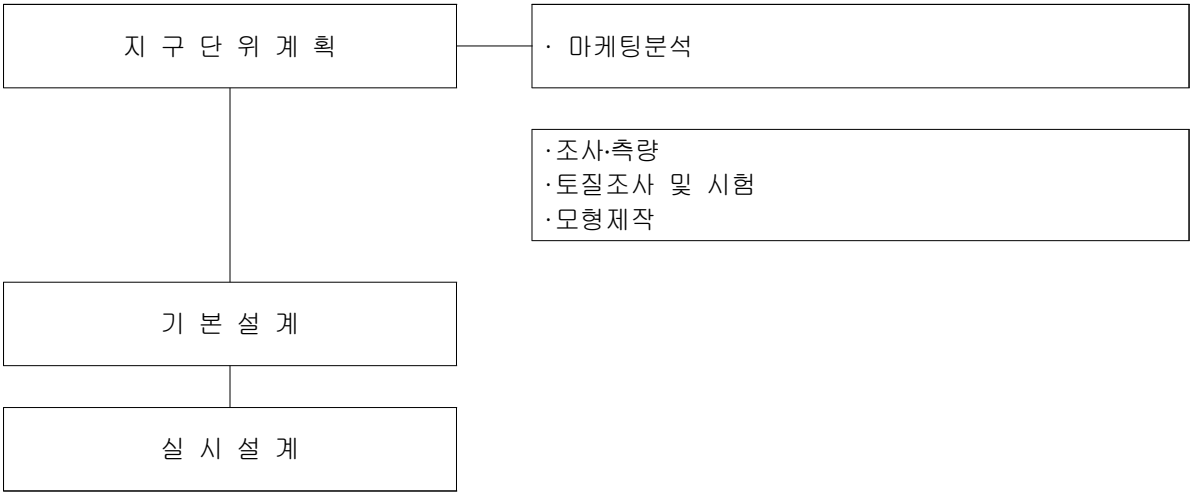

2. 과업수행 추진과정

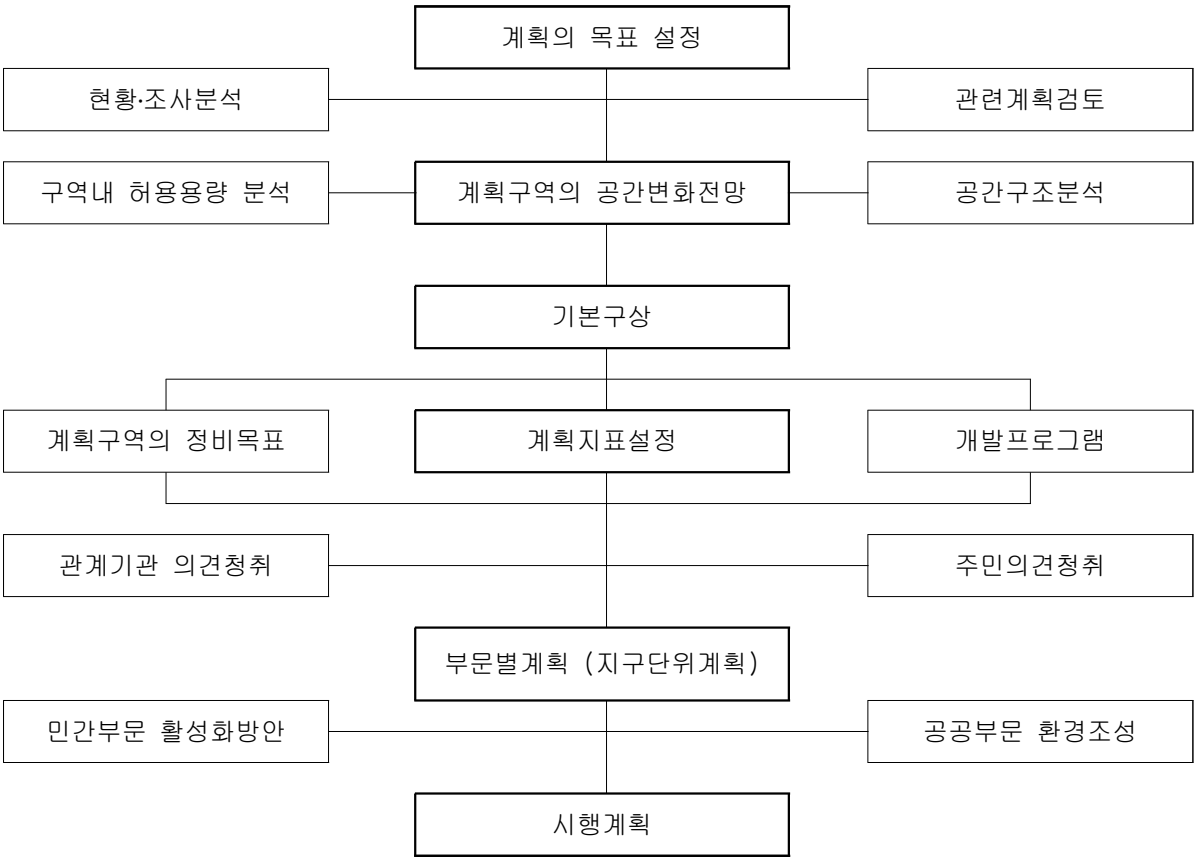

1-4 품 산정의 원단위 산정과 기준

1-4-1 표준품 산정내역

○ 표준품 산정의 기준이 되는 비목은 제1장 총칙에서 제시한 비목을 중심으로 하였으며, 이는 지구단위계획에 필요한 사항만을 대상으로 한다.

○ 표준품 산정의 기본이 되는 직접인건비 품의 작업항목별 보할은 업무의 난이도를 감안하여 설정토록 한다.

1. 구역지정

종 별		내 용	세부항목	단 위	비 고
직접비	직접인건비	1.현황조사 및 분석	①자연환경 ②인구 및 산업현황 ③토지소유 및 이용현황 ④건축물 현황 ⑤교통현황 ⑥기반시설현황 ⑦도시계획현황 및 관련계획 ⑧가로시설물 및 조경환경 ⑨문제점 및 잠재력	인·일 〃 〃 〃 〃 〃 〃 〃 〃	
		2.기본구상	①과제정립 및 목표설정 ②기본방향 및 지표설정 ③토지이용체계구상 ④교통동선체계구상 ⑤공원·녹지체계구상	〃 〃 〃 〃 〃	
		3.부문별기본방향	①용도지역·지구 ②교통처리 ③공원녹지 ④기반시설 ⑤가구 및 획지 ⑥건축물 ⑦경관 ⑧환경관리	〃 〃 〃 〃 〃 〃 〃 〃	
		4.성과품 작성	①보고서작성 및 편집 ②관련도서작성	〃 〃	
		5.기술협의	①공청회/주민설명회 ②주민간담회/시민계획단 ③위원회심의 지원 ④관계기관 협의	〃 〃 〃 〃	
	직접경비	여비, 인쇄비, 조감도, 회의준비비, 현장운영비 등		식	제1장 총칙참조
간접비	제경비	(직접인건비)×120%		〃	〃
	기술료	(직접인건비+제경비) ×30%		〃	〃

2. 지구단위계획

종 별		내 용	세부항목	단 위	비 고
직접비	직접인건비	1.현황조사 및 여건분석	①자연환경 ②인구 및 산업현황 ③토지소유 및 이용현황 ④건축물 현황 ⑤교통현황 ⑥기반시설현황 ⑦도시계획현황 및 관련계획 ⑧가로시설물 및 조경환경 ⑨문제점 및 잠재력	인·일 〃 〃 〃 〃 〃 〃 〃 〃	
		2.기본구상	①과제정립 및 목표설정 ②기본방향 및 지표설정 ③토지이용체계구상 ④교통동선체계구상 ⑤공원·녹지체계구상	〃 〃 〃 〃 〃	
		3.부문별 계획	①용도지역·지구계획 ②교통처리계획 ③공원녹지계획 ④기반시설계획 ⑤가구 및 획지계획 ⑥건축물에 관한 계획 ⑦경관계획 ⑧특별계획구역 계획 ⑨주요지구스케치모델 ⑩환경관리계획	〃 〃 〃 〃 〃 〃 〃 〃 〃 〃	
		4.시행계획	①도시계획결정 ②집행계획	〃 〃	
		5.성과품 작성	①보고서작성 및 편집 ②관련도서작성	〃 〃	
		6.기술협의	①공청회/주민설명회 ②주민간담회/시민계획단 ③위원회심의 지원 ④관계기관 협의	〃 〃 〃 〃	
		7.마케팅 분석	표준 평가서	〃	
		8.토질조사 및 시험	토질조사 및 시험품 별도적용		
		9.조사측량	측량품 별도적용		
		10.기본설계	엔지니어링사업대가의 기준 중 건설부문 공사비요율을 적용		
		11.실시설계	엔지니어링사업대가의 기준 중 건설부문 공사비요율을 적용		
	직접경비	여비, 인쇄비, 조감도, 회의준비비, 현장운영비 등		식	제1장 총칙참조
간접비	제경비	(직접인건비)×120%		〃	〃
	기술료	(직접인건비+제경비) ×30%		〃	〃

주 : 경제마케팅 분석, 각종영향평가, 공원 등 단위 도시·군계획시설의 조성계획 및 이에 준하는 사항, 모형제작 및 개별 필지별 건축물의 내용을 구체화하는 건축계획설계단계 및 이에 준하는 사항 등과, 사업추진 시 필요한 조사·측량, 토질조사 및 시험, 기본설계, 실시설계는 별도의 엔지니어링 활동업무로 계상하도록 한다.

1-4-2 산정 기준

1. 계획·기준면적의 선정

○ 사업의 조사설계 산정의 원단위 책정의 기준을 마련하기 위하여 기준면적을 구역면적 10만㎡로 산정 하였다.

○ 계획면적의 산정은 지구단위계획구역으로 지정된 면적을 기준으로 한다.

○ 지구단위계획을 유사용역으로 활용하고자 하는 경우에는 대상지와 인접하여 있는 도로와 대상지내 공공시설을 포함하여 계획면적으로 산정한다.

○ 계획관리지역이나 개발진흥지구에서의 지구단위계획 중 체육시설, 관광지에 대한 계획은 건축물, 도로, 주차장용지 등 시설부지를 계획대상지로 하며 계획대상지 면적이 3만㎡에 미달할 때에는 3만㎡를 계획면적으로 적용한다.

2. 표준품의 산정방법

○ 표준품의 적용에 있어 기준면적과 계획면적의 차이에 따른 품 산정은 아래의 수정식에 따라 기준면적의 소요작업량을 수정하여 산정한다.

○ 소요작업량 = 기준면적소요작업량 × 면적보정계수(α) × 시가화보정계수(β)

3. 계획안의 수정과 과업중지에 다른 품 산정방법

○ 계획안이 작성되고 주민공람, 의회보고 등 행정절차과정을 거쳐 계획안이 확정된 후 발주자의 사정에 의하여 계획안이 일부변경·재작업이 수행되는 경우에는 그 변경· 재작업의 정도에 따라 엔지니어링사업대가의 50～100% 수준에서 비용을 추가 지급하여야 한다.

○ 과업수행 중 발주자의 사정에 따른 과업 중단으로 인해 정부 회계연도가 경과되어 현저한 비용의 차이가 발생하였을 경우에는 엔지니어링사업대가를 당해 신년도의 노임단가를 기준으로 재산정하여야 한다.

1-4-3 단위별 변화수정과 보정

1. 작업량 보정계수 산정

1) 면적의 대소에 대한 작업량 보정계수 산정

○ 지구단위계획면적이 기준면적을 초과하거나 이에 못 미치는 경우의 직접인력 소요작업량의 산정을 위한 각 작업내용별 보정계수(α)는 다음과 같이 산정한다.

$$\alpha = \left(\frac{\text{계획면적}}{\text{기준면적}}\right)^{0.6} = \left(\frac{A}{10}\right)^{0.6}$$

α = 보정계수
A = 계획면적(만㎡)

계획면적에 대한 작업량 보정계수

면적 (만㎡)	보정계수 (α)	면적 (만㎡)	보정계수 (α)
3	0.486	70	3.214
5	0.660	100	3.981
10	1.000	150	5.078
30	1.933	200	6.034
50	2.627	300	7.696

주 : 계획면적이 3만㎡ 미만인 경우에는 계획면적 3만㎡를 기준으로 하여 산정한다.

2) 지구밀도의 변화에 대한 작업량 보정계수 산정

지구밀도변화에 따른 보정계수

구 분	지구밀도보정계수(β)
1.신시가지 또는 신개발지 - 계획에 의해 조성중인 지역 및 미개발구역	1.00
2.기존 시가지 - 기존 시가지의 정비·관리·보존 등의 계획이 필요한 구역	1.50
3.복합구역 - 신시가지(신개발지)와 기존 시가지가 혼재된 구역	1.25

주 : 1개의 계획구역에 2개 이상의 특성이 다른 지역이 포함될 때에는 각 지역의 특성에 따른 보정계수로 구분 산정한다.

2. 직접인건비 소요 작업량 산정

○ 계획면적의 대소에 따른 직접인력 소요작업량의 산정방법은 아래와 같이 기준면적의 직능별 직접인력 소요작업량에 계획단위 보정계수(α, β)을 곱하여 산출한다.

구 분	기준면적 (만㎡)	총작업량 (인·일)					
		기술사	특 급	고 급	중 급	초 급	보조원
구역지정	10	10.8αβ	18.2αβ	44.2αβ	61.8αβ	114.9αβ	138.0αβ
지구단위계획	10	33.1αβ	53.1αβ	132.4αβ	162.8αβ	344.6αβ	446.2αβ

1-5 표준단위 업무분류와 원단위

1. 구역지정

기술업무의 직능별 직접인력 소요작업량(면적10만㎡ 기준)

(단위 : 인·일/표준단위)

구 분	업무내용	표준단위	소요인력						비고
			기술사	특 급	고 급	중 급	초 급	보조원	
1. 현황조사 및 여건분석	①자연환경	10만㎡	0.1	0.2	0.6	1.0	1.3	2.0	
	②인구 및 산업현황	10만㎡	0.1	0.2	0.6	1.5	2.4	2.5	
	③토지소유 및 이용현황	10만㎡	0.2	0.5	1.2	2.3	3.6	4.6	
	④건축물 현황	10만㎡	0.2	0.5	1.2	3.2	3.7	4.4	
	⑤교통현황	10만㎡	0.1	0.3	0.6	1.8	2.4	3.4	
	⑥기반시설현황	10만㎡	0.1	0.3	0.4	1.1	1.5	2.5	
	⑦도시계획현황 및 관련계획	10만㎡	0.1	0.3	0.4	1.3	1.8	1.9	
	⑧가로시설물 및 조경환경	10만㎡	0.1	0.3	0.6	1.1	1.3	2.1	
	⑨문제점 및 잠재력	10만㎡	0.1	0.3	0.6	1.1	1.3	-	
	소 계		1.1	2.9	6.2	14.4	19.3	23.4	
2.기본구상	①과제정립 및 목표설정	10만㎡	0.1	0.1	0.7	0.9	1.8	2.5	
	②기본방향 및 지표설정	10만㎡	0.2	0.4	1.1	1.0	2.2	3.0	
	③토지이용체계구상	10만㎡	0.2	0.4	1.2	1.0	2.2	3.0	
	④교통동선체계구상	10만㎡	0.1	0.2	0.9	0.8	1.8	3.0	
	⑤공원·녹지체계구상	10만㎡	0.2	0.4	1.1	0.9	2.2	3.0	
	소 계		0.8	1.5	5.0	4.6	10.2	14.5	
3.부문별계획	①용도지역·지구	10만㎡	0.6	0.9	2.5	1.3	7.8	8.8	
	②교통처리	10만㎡	0.9	1.4	3.0	2.9	7.5	12.9	
	③공원녹지	10만㎡	0.3	0.5	1.5	1.3	2.5	4.3	
	④기반시설	10만㎡	1.1	1.6	5.0	5.7	10.9	10.9	
	⑤가구 및 획지	10만㎡	1.2	0.7	1.8	1.8	6.1	6.9	
	⑥건축물	10만㎡	2.3	3.2	7.0	9.0	18.6	20.7	
	⑦경관	10만㎡	0.6	0.9	1.8	1.5	5.0	8.6	주1
	⑧환경관리	10만㎡	-	-	-	-	-	-	주2
	소 계		7.0	9.2	22.6	23.5	58.4	73.1	
4.성과품작성	①보고서작성 및 편집	10만㎡	1.5	3.1	6.9	11.6	11.6	7.7	
	②관련도서작성	10만㎡	0.4	1.5	3.5	7.7	15.4	19.3	
	소 계		1.9	4.6	10.4	19.3	27.0	27.0	
총 계			10.8	18.2	44.2	61.8	114.9	138.0	
5.기술협의	①공청회/주민설명회	1식	2.0	2.0	2.0	4.0	4.0	4.0	주3
	②주민간담회/시민계획단	1식	2.0	2.0	2.0	4.0	4.0	4.0	
	③위원회심의 지원	1식	2.0	2.0	2.0	4.0	4.0	4.0	
	④관계기관 협의	1식	2.0	2.0	2.0	4.0	4.0	4.0	
	소 계		8.0	8.0	8.0	16.0	16.0	16.0	

주 : ①경관심의 및 지구경관계획은 필요시 제7장 경관심의 및 지구경관계획의 엔지니어링품을 별도 적용한다.

②환경관리계획은 과업의 특성에 따라 별도 환경영향평가의 품을 고려하여 비용을 가산한다.

③기술협의는 2회 이내 기준이며, 횟수가 늘어날 경우 증가배수에 해당하는 작업품과 비용을 가산한다. (필요항목 선택적 적용)

④계획의 상세정도(詳細程度), 포함되는 항목에 따라 선택적으로 적용이 가능한 항목에 대해서는 과업지시서의 내용에 따라 일부를 증감할 수 있다.

-지구단위계획에 대한 구체적인 지침을 제시하지 않고, 개발을 위한 방침만을 설정할 경우에는 시행계획을 포함하지 아니한다.

-특별계획구역이 포함되지 아니하는 소규모의 지구단위계획은 특별계획구역의 방향설정을 포함하지 아니한다.

⑤개별법에 의한 개발사업으로 추진하면서 기본계획이 수립되어 있는 경우에는 부문별계획의 내용을 기존계획의 검토항목을 50%까지 적용할 수 있다.

2. 지구단위계획

기술업무의 직능별 직접인력 소요작업량(면적10만㎡ 기준)

(단위 : 인·일/표준단위)

구 분	업무내용	표준단위	소요인력						비고
			기술사	특 급	고 급	중 급	초 급	보조원	
1. 현황조사 및 여건분석	①자연환경	10만㎡	0.4	0.7	1.8	2.9	3.9	6.0	
	②인구 및 산업현황	10만㎡	0.4	0.7	1.8	4.4	7.1	7.4	
	③토지소유 및 이용현황	10만㎡	0.7	1.5	3.6	8.8	10.9	13.7	
	④건축물 현황	10만㎡	0.6	1.5	3.6	9.5	11.1	13.3	
	⑤교통현황	10만㎡	0.4	0.8	1.8	5.3	7.2	10.2	
	⑥기반시설현황	10만㎡	0.4	0.8	1.3	3.2	4.3	7.4	
	⑦도시계획현황 및 관련계획	10만㎡	0.4	0.8	1.3	3.6	5.3	5.6	
	⑧가로시설물 및 조경환경	10만㎡	0.4	0.8	1.8	2.9	3.9	6.2	
	⑨문제점 및 잠재력	10만㎡	0.4	0.8	1.8	2.9	3.9	0.0	
	소 계		4.1	8.4	18.8	43.5	57.6	69.8	
2.기본구상	①과제정립 및 목표설정	10만㎡	0.3	0.5	2.2	2.5	5.6	7.4	
	②기본방향 및 지표설정	10만㎡	0.6	1.0	3.4	2.9	6.7	9.0	
	③토지이용체계구상	10만㎡	0.6	1.1	3.4	2.9	6.7	9.0	
	④교통동선체계구상	10만㎡	0.3	0.6	2.9	2.5	5.6	9.0	
	⑤공원·녹지체계구상	10만㎡	0.6	1.0	3.3	2.9	6.7	9.0	
	소 계		2.4	4.2	15.2	13.7	31.3	43.4	
3.부문별계획	①용도지역·지구계획	10만㎡	1.9	2.9	7.4	3.9	23.4	26.5	
	②교통처리계획	10만㎡	2.8	4.2	9.8	8.5	22.6	38.6	
	③공원녹지계획	10만㎡	0.9	1.4	4.4	4.0	7.4	12.9	
	④기반시설계획	10만㎡	3.4	4.8	14.8	17.4	32.5	32.6	
	⑤가구 및 획지계획	10만㎡	1.4	2.1	5.3	5.2	18.2	20.9	
	⑥건축물에 관한 계획	10만㎡	7.0	9.7	21.1	27.1	55.7	62.6	
	⑦경관계획	10만㎡	1.9	2.8	5.3	4.5	15.1	25.7	
	⑧특별계획구역 계획	10만㎡	0.8	1.3	3.0	2.5	8.8	10.1	
	⑨주요지구스케치모델	10만㎡	0.6	1.1	4.5	4.3	15.1	25.3	주1
	⑩환경관리계획	10만㎡	-	-	-	-	-	-	주2
	소 계		20.7	30.3	75.6	77.4	198.8	255.2	
4.시행계획	①도시계획결정	10만㎡	2.0	2.8	6.2	4.4	15.0	25.5	
	②집행계획	10만㎡	2.0	2.8	6.2	4.5	14.9	25.3	
	소 계		4.0	5.6	12.4	8.9	29.9	50.8	
5.성과품작성	①보고서작성 및 편집	10만㎡	1.5	3.1	6.9	11.6	11.6	7.7	
	②관련도서작성	10만㎡	0.4	1.5	3.5	7.7	15.4	19.3	
	소 계		1.9	4.6	10.4	19.3	27.0	27.0	
총 계			33.1	53.1	132.4	162.8	344.6	446.2	
6. 기술협의	①공청회/주민설명회	1식	2.0	2.0	2.0	4.0	4.0	4.0	주3
	②주민간담회/시민계획단	1식	2.0	2.0	2.0	4.0	4.0	4.0	
	③위원회심의 지원	1식	2.0	2.0	2.0	4.0	4.0	4.0	
	④관계기관 협의	1식	2.0	2.0	2.0	4.0	4.0	4.0	
	소 계		8.0	8.0	8.0	16.0	16.0	16.0	

주 : ①경관심의 및 지구경관계획은 필요시 제7장 경관심의 및 지구경관계획의 엔지니어링품을 별도 적용한다.

②환경관리계획은 과업의 특성에 따라 별도 환경영향평가의 품을 고려하여 비용을 가산한다.

③기술협의는 2회 이내 기준이며, 횟수가 늘어날 경우 증가배수에 해당하는 작업품과 비용을 가산한다. (필요항목 선택적 적용)

④계획의 상세정도(詳細程度), 포함되는 항목에 따라 선택적으로 적용이 가능한 항목에 대해서는 과업지시서의 내용에 따라 일부를 증감할 수 있다.

-지구단위계획에 대한 구체적인 지침을 제시하지 않고 개발을 위한 방침만을 설정할 경우에는 시행계획을 포함하지 아니한다.

-특별계획구역이 포함되지 아니하는 소규모의 지구단위계획은 특별계획구역의 방향설정을 포함하지 아니한다.

⑤개별법에 의한 개발사업으로 추진하면서 기본계획이 수립되어 있는 경우에는 부문별계획의 내용을 기존계획의 검토항목을 50%까지 적용할 수 있다.

1-6 주요업무내용

1. 구역지정

구 분	항 목		내 용
1.현황조사 및 분석	①자연환경		·지형, 지세, 기상, 수계 등 조사
	②인구 및 산업현황		·상주인구, 가구규모, 취업인구 등 인구 및 산업관련 현황 조사
	③토지소유 및 이용현황		·토지의 소유, 지목, 이용상태 등 조사
	④건축물현황		·건축물의 용도, 층수, 구조, 용적률, 배치, 형태, 색채 등 건물현황 조사
	⑤교통현황		·도로, 차량, 보행자, 교통시설 등 교통관련 현황 조사
	⑥기반시설현황		·의료,보건,사회복지,교육,문화,체육시설,공원·녹지 등 ·구역내외의 상수도, 하수도, 에너지공급 등 공급처리시설 현황조사
	⑦도시계획현황 및 관련계획		·용도지역·지구·구역, 도시·군계획시설 현황, 기타 상위 및 관련계획 검토
	⑧가로시설물 및 조경환경		·가로시설물·조경 등
	⑨문제점 및 잠재력 분석		
2.기본구상	①과제정립 및 목표설정		·구역내 문제점 유형화 및 도시정비적 측면에서 인접지역을 고려한 정비방향제시
	②기본방향 및 지표설정		·도시계획 및 설계의 제어요소 등 법적사항 검토 포함
	③토지이용체계구상		·공간구성체계설정 ·토지이용구상안 작성
	④교통동선체계구상		·이용자의 이용체계구상 ·토지이용에 따른 기능별 교통동선체계 구상
	⑤공원·녹지체계 구상		
3.부문별 계획	①용도 지역· 지구	·세부토지이용	·도시계획의 내용을 구체화한 대상구역의 토지이용계획
		·용도지역·지구세분	
	②교통처리	·교통분석 및 동선	·대상구역 및 주변지역의 차량 및 보행자에 대한 교통처리계획 및 시설계획 ·교통량예측 및 배분 포함
		·교통시설	
		·교통처리	
	③공원녹지	·공원·녹지	·대상구역 및 주변지역의 공원녹지시설계획 -생태도시 조성방향 포함
	④기반시설	·공급처리시설 용량 예측	·상수도 및 하수도, 전기 · 통신계획 및 에너지(Gas등)소요량 예측
		·에너지 등 자원의 절약 및 재활용 계획	
		·생활환경시설계획	
		·기타 도시기반시설계획	
	⑤가구 및 획지	·가구 및 획지계획	·기존 대지규모 및 용도지역지구에 적합한 가구 및 획지규모에 대한 계획 및 조정계획
		·가구 및 획지 조정계획	

구 분	항 목		내 용
3.부문별 계획 (계속)	⑥건축물	·건축물 용도	·가구 및 획지조정계획에 따른 건축물 및 시설배치, 용도, 밀도, 높이, 형태, 색채 및 건축선에 대한 계획
		·건축물 밀도	
		·건축물 높이	
		·건축물 배치 및 건축선	
		·건축물의 형태 및 색채	
		·기타	·공동 개발 및 합벽건축, 대지안의 공지, 공개공지 등
	⑦경관	·도시경관구조분석	·건축물의 색채와 외부환경에 대한 계획 ·도시내 주요간선도로 등 도시의 경관축을 이루는 가로변의 건축물이나 수목, 조형물에 대한 조성지침 ·보행자를 위한 가로환경 및 가로시설물에 대한 계획
		·도시축별 경관계획	
		·건축물 외관계획	
		·색채계획	
		·기타 역사·문화 경관 계획 등	
	⑧환경관리계획		·환경보전 및 관리계획 ·재해방지계획

2. 지구단위계획

구 분	항 목	내 용
1.현황조사 및 분석	①자연환경	·지형, 지세, 기상, 수계 등 조사
	②인구 및 산업현황	·상주인구, 가구규모, 취업인구 등 인구 및 산업관련 현황 조사
	③토지소유 및 이용현황	·토지의 소유, 지목, 이용상태 등 조사
	④건축물현황	·건축물의 용도, 층수, 구조, 용적률, 배치, 형태, 색채 등 건물현황 조사
	⑤교통현황	·도로, 차량, 보행자, 교통시설 등 교통관련현황 조사
	⑥기반시설현황	·의료, 보건, 사회복지, 교육, 문화, 체육시설, 공원·녹지 등 ·구역내외의 상수도, 하수도, 에너지공급 등 공급처리시설 현황조사
	⑦도시계획현황 및 관련계획	·용도지역·지구·구역, 도시·군계획시설 현황, 기타 상위 및 관련계획 검토
	⑧가로시설물 및 조경환경	·가로시설물·조경 등
	⑨문제점 및 잠재력 분석	

구 분	항 목		내 용
2.기본구상	①과제정립 및 목표설정		·구역 내 문제점 유형화 및 도시정비적 측면에서 인접지역을 고려한 정비방향제시
	②기본방향 및 지표설정		·도시계획 및 설계의 제어요소 등 법적사항 검토 포함
	③토지이용체계구상		·공간구성체계설정 ·토지이용구상안 작성
	④교통동선체계구상		·이용자의 이용체계구상 ·토지이용에 따른 기능별 교통동선체계 구상
	⑤공원·녹지체계 구상		
3.부문별계획	①용도지역 · 지구계획	·세부토지이용	·도시계획의 내용을 구체화한 대상구역의 토지이용계획
		·용도지역·지구 세분	
	② 교 통 처 리 계획	·교통분석 및 동선	·대상구역 및 주변지역의 차량 및 보행자에 대한 교통처리계획 및 시설계획 ·교통량예측 및 배분 포함
		·교통시설	
		·교통처리	
		·교통시설의 배치와 규모계획	
	③ 공 원 녹 지 계획	·공원·녹지	·대상구역 및 주변지역의 공원녹지시설계획 -생태도시 조성방향 포함
		·공원·녹지시설의 배치와 규모계획	
	④ 기 반 시 설 계획	·공급처리시설 용량 예측	·상수도 및 하수도, 전기 · 통신계획 및 에너지(Gas등)소요량 예측
		·에너지 등 자원의 절약 및 재활용 계획	·지역에 적합한 에너지 등 자원에 대한 절약 및 재활용 계획 및 조정계획
		·생활환경시설계획	·지역에 적합한 생활환경시설에 대한 계획 및 조정계획
		·기타 도시기반 시설 계획	·지역에 적합한 도시기반시설에 대한 계획 및 조정계획
		·도시기반시설의 배치와 규모계획	·각종 도시기반시설에 대한 규모 및 배치계획 및 조정계획
	⑤가구 및 획지 계획	·가구 및 획지 계획	·기존 대지규모 및 용도지역·지구에 적합한 가구 및 획지규모에 대한 계획 및 조정계획
		·가구 및 획지 조정 계획	
	⑥ 건 축 물 에 관한 계획	·건축물 용도	·가구 및 획지조정계획에 따른 건축물 및 시설배치, 용도, 밀도, 높이, 형태, 색채 및 건축선에 대한 계획
		·건축물 밀도	
		·건축물 높이	
		·건축물 배치 및 건축선	
		·건축물의 형태 및 색채	
		·기 타	·공동개발 및 합벽건축, 대지안의 공지, 공개공지 등
	⑦경관계획	·도시경관구조 분석	·건축물의 색채와 외부환경에 대한 계획 ·도시 내 주요간선도로 등 도시의 경관축을 이루는 가로변의 건축물이나 수목, 조형물에 대한 조성지침 ·보행자를 위한 가로환경 및 가로시설물에 대한 계획
		·도시축별 경관 계획	
		·건축물 외관 계획	
		·색채계획	
		·기타 역사·문화경관계획 등	

구 분	항 목	내 용
3.부문별계획 (계속)	⑧특별계획구역계획	·지구단위계획에 의하여 특별계획구역을 지정한 경우 특별계획구역별 지정목적, 계획방향, 개략적인 계획 지침 등
	⑨주요지구 스케치 모델계획	·건축규모 및 공간계획의 예시
	⑩환경관리계획	·환경보전 및 관리계획 ·재해방지계획
4. 시행계획	①도시계획결정	·지구단위계획의 결정내용 및 절차포함
	②집행계획	·단계별 시행계획 포함

1-7 표준성과품

성과구분	표준성과도서			비 고
	구 분	규 격	제출부수	
현황도	·주변구역 현황도 ·토지이용 현황도 ·건축물 현황도 ·도시계획 현황도		1부 〃 〃 〃	·토지이용, 기타관련사항 ·토지이용현황 ·용도, 구조, 층수 ·용도지역지구, 도시·군계획시설
계획도	·종합개념도		1부	·토지이용체계, 교통체계, 공원녹지체계
	·도시계획도	1/3,000 ~ 1/5,000	〃	·용도지역·지구의 세분, 도시·군계획시설 등
	·교통처리계획도		〃	·도시계획도로 및 세가로의 배치, 차량 및 보행자동선처리계획, 주차장 등
	·건축물계획도		〃	·용도, 건폐율, 용적률, 높이, 배치, 건축선 등
보고서	·지구단위계획 보고서·심의용 보고서	발주자와 협의결정	발주자와 협의결정	

주 : ①제출부수 및 성과품 종류가 증가할 경우에는 증가배수에 해당하는 작업품과 비용을 가산한다.
②계획보고서 및 기타 관련자료의 규격 및 제출부수는 발주자와의 협의에 의하여 비용을 산정한다.

제2절 마을만들기

2-1 정 의

○ 마을만들기는 특정 지역사회를 대상으로 주민이 주체가 되어 행정과 전문가, 민간섹터 등과 함께 해당 지역이 가진 전통이나 특징, 자원 등을 활용하여 주거환경개선, 교육, 문화, 복지, 경관, 경제 등 다양한 분야에서의 발전을 위하여 노력하는 총체적 활동을 의미한다.

2-2 자료제공의 전제

○ 당해 계획의 수립에 필요한 모든 관련자료는 원칙적으로 발주자가 제공하는 것으로 하되, 발주자가 보유하지 않는 자료는 엔지니어링사업자가 조사·수집한다.

○ 발주자가 제공하지 못하는 자료의 조사에 있어서는 그 규모·내용에 의거하여 별도의 엔지니어링사업대가를 산정하여 엔지니어링사업자가 수행하며, 관련자료의 기밀성과 광범위한 자료가 필요할 경우 조사·분석에 필요한 상당기간과 자료수집비용이 전제되어야 한다.

2-3 업무범위와 추진과정

2-3-1 업무범위

○ 마을만들기의 업무범위는 마을만들기 사업을 진행하는데 있어 현황 및 문제점을 파악하고, 지역 자원 등의 조사, 분석, 평가, 진단을 통하여 각 마을별 주민이 공감할 수 있는 마을의 미래와 목표를 마련하고, 마을별 특화된 기본구상과 마을계획도 작성 및 지속가능한 관리 및 운영방안 마련 등의 내용을 포함하는 것으로 한다.

2-3-2 추진과정

○ 타부처(관계기관)와 협의나 전문가 자문 등에 소요되는 기간은 과업수행기간에서 제외하여 그 소요기간만큼 과업수행기간을 연장하여야 한다.

1. 과업수행 추진과정

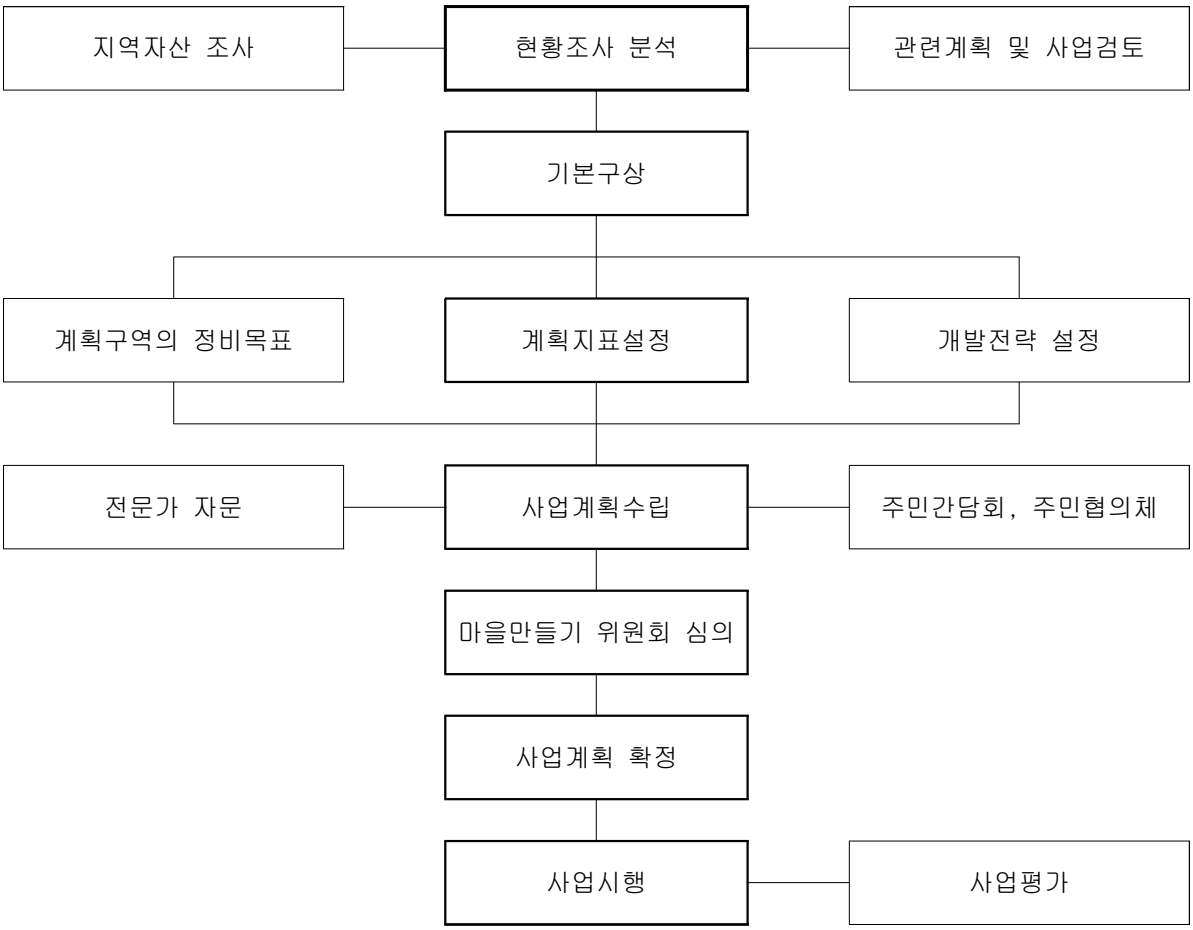

2-4 품 산정의 원단위 산정과 기준

2-4-1 표준품 산정내역

○ 표준품 산정의 기준이 되는 비목은 제1장 총칙에서 제시한 비목을 중심으로 하였으며, 이는 마을만들기 업무에 필요한 사항만을 대상으로 한다.

○ 표준품 산정의 기본이 되는 직접인건비 품의 작업항목별 보할은 항목별 업무의 난이도를 감안하여 설정토록 한다.

종 별		내 용	세부내용	단 위	비 고
직접비	직접인건비	1.현황조사 및 분석	①지역자산조사 ②관련계획 및 사업 ③문제점 및 잠재력	인·일 〃 〃	
		2.기본구상	①정비목표 및 구현 전략의 설정 ②기본방향 및 지표설정	〃 〃	
		3.부문별계획	①마스터플랜 수립 ②사업추진계획 ③단계별 시행계획	〃 〃 〃	
		4.주민워크샵	①주민의견 수렴 ②주민역량 강화 ③주민공동체 조직구성 ④마을공동체 프로그램 운영계획 ⑤사회경제적 재생방안	〃 〃 〃 〃 〃	
		5.성과품작성	①보고서작성 및 편집 ②관련도서작성	〃 〃	
		6.기술협의	①공청회/주민설명회 ②주민간담회/시민계획단 ③위원회심의 지원 ④관계기관 협의	〃 〃 〃 〃	
	직접경비	여비, 인쇄비, 조감도, 회의준비비, 현장운영비 등		식	제1장 총칙참조
간접비	제경비	(직접인건비)×120%		〃	〃
	기술료	(직접인건비+제경비) × 30%		〃	〃

2-4-2 산정 기준

1. 계획·기준면적의 선정

○ 사업의 조사 설계 산정의 원단위 책정의 기준을 마련하기 위하여 기준면적을 대상지 면적 10만㎡로 산정 하였다.

○ 계획면적의 산정은 마을만들기사업구역으로 지정된 면적을 기준으로하며, 계획 대상지 면적이 1만㎡에 미달할 때에는 1만㎡를 계획면적으로 적용한다.

2. 표준품의 산정방법

○ 표준품의 적용에 있어 기준면적과 계획면적의 차이에 따른 품 산정은 아래의 수정식에 따라 기준면적의 소요작업량을 수정하여 산정한다.

○ 소요작업량 = 기준면적소요작업량 × 면적보정계수(α)

3. 계획안의 수정과 과업중지에 다른 품 산정방법

○ 계획안이 작성되고 주민의견청취 등 행정절차과정을 거쳐 계획안이 확정된 후 발주자의 사정에 의하여 계획안이 일부변경·재작업이 수행되는 경우에는 그 변경 · 재작업의 정도에 따라 엔지니어링사업대가의 50～100% 수준에서 비용을 추가 지급하여야 한다.

○ 과업수행 중 발주자의 사정에 따른 과업 중단으로 인해 정부 회계연도가 경과되어 현저한 비용의 차이가 발생하였을 경우에는 엔지니어링사업대가를 당해 신년도의 노임단가를 기준으로 재산정하여야 한다.

2-4-3 단위별 변화수정과 보정

1. 작업량 보정계수 산정

1) 면적의 대소에 대한 작업량 보정계수 산정

○ 마을만들기 사업면적이 기준면적을 초과하거나 이에 못 미치는 경우의 직접인력 소요작업량의 산정을 위한 각 작업내용별 보정계수(α)는 다음과 같이 산정한다.

$$\alpha = \left(\frac{\text{계획면적}}{\text{기준면적}}\right)^{0.6} = \left(\frac{A}{10}\right)^{0.6}$$

α = 보정계수
A = 계획면적(만㎡)

계획면적에 대한 작업량 보정계수

면 적 (만㎡)	보정계수 (α)	면 적 (만㎡)	보정계수 (α)
1	0.251	30	1.933
3	0.486	50	2.627
5	0.660	70	3.214
10	1.000	80	3.482
20	1.516	90	3.737

주 : 계획면적이 1만㎡ 미만인 경우에는 계획면적 1만㎡를 기준으로 하여 산정한다.

2) 직접인건비 소요 작업량 산정

○ 계획면적의 대소에 따른 직접인력 소요작업량의 산정방법은 아래와 같이 기준면적의 직종별 직접인력 소요작업량에 계획단위 보정계수(α)를 곱하여 산출한다.

구 분	기준면적 (만㎡)	총작업량(인·일)					
		기술사	특 급	고 급	중 급	초 급	보조원
마을만들기	10	9.9α	19.1α	48.1α	90.9α	133.2α	146.0α

2-5 표준단위 업무분류와 원단위

기술업무의 직능별 직접인력 소요작업량 (면적10만㎡ 기준)

(단위 : 인·일/표준단위)

구 분	업무내용	표준단위	소요인력						비고
			기술사	특 급	고 급	중 급	초 급	보조원	
1.현황조사 및 분석	①지역자산조사	10만㎡	0.3	0.6	2.8	6.2	9.4	11.7	
	②관련계획 및 사업	10만㎡	0.3	0.7	2.8	6.2	9.4	11.7	
	③문제점 및 잠재력	10만㎡	0.4	0.7	2.8	6.2	9.4	11.7	
	소 계		1.0	2.0	8.4	18.6	28.2	35.1	
2.기본구상	①정비목표 및 구현 전략의 설정	10만㎡	0.7	1.3	1.7	2.5	2.7	3.6	
	②기본방향 및 지표설정	10만㎡	0.8	1.4	1.9	2.7	3.3	4.4	
	소 계		1.5	2.7	3.6	5.2	6.0	8.0	
3.부문별계획	①마스터플랜 수립	10만㎡	0.4	1.1	3.4	7.3	8.6	7.4	
	②사업추진계획	10만㎡	0.3	1.1	3.4	7.3	8.6	7.4	
	③단계별 시행계획	10만㎡	0.3	1.1	3.4	7.3	8.6	7.4	
	소 계		1.0	3.3	10.2	21.9	25.8	22.2	
4.주민워크샵	①주민의견 수렴	10만㎡	0.1	0.4	1.2	4.1	5.6	6.8	주1
	②주민역량 강화	10만㎡	0.1	0.4	1.2	4.1	5.6	6.8	
	③주민공동체 조직구성	10만㎡	0.1	0.4	1.0	2.8	3.3	3.9	
	④마을공동체 프로그램 운영계획	10만㎡	3.7	5.1	11.3	14.6	30.1	33.7	
	⑤사회경제적 재생방안	10만㎡	0.2	0.4	1.2	1.1	2.6	3.5	
	소 계		4.2	6.7	15.9	26.7	47.2	54.7	
5.성과품작성	①보고서작성 및 편집	10만㎡	1.5	2.9	6.7	11.1	11.2	7.5	
	②관련도서작성	10만㎡	0.7	1.5	3.3	7.4	14.8	18.5	
	소 계		2.2	4.4	10.0	18.5	26.0	26.0	
계			9.9	19.1	48.1	90.9	133.2	146.0	
6.기술협의	①공청회/주민설명회	1식	2.0	2.0	2.0	4.0	4.0	4.0	주2
	②주민간담회/시민계획단	1식	2.0	2.0	2.0	4.0	4.0	4.0	
	③위원회심의 지원	1식	2.0	2.0	2.0	4.0	4.0	4.0	
	④관계기관 협의	1식	2.0	2.0	2.0	4.0	4.0	4.0	
	소 계		8.0	8.0	8.0	16.0	16.0	16.0	

주 : ①본 과업 수행 엔지니어링사업자외의 자가(마을만들기 지원센터 등) 수행할 경우 제외할 수 있음

②기술협의는 2회 이내 기준이며, 횟수가 늘어날 경우 증가배수에 해당하는 작업품과 비용을 가산한다. (필요항목 선택적 적용)

2-6 주요업무내용

구 분	항 목	내 용
1.현황조사 및 분석	①지역자산조사	·대상마을 인문현황, 경제활동, 역사문화자원, 생태자원 등 조사 및 분석
	②관련계획 및 사업	·상위계획 및 관련계획 검토 ·지역개발사업현황 및 주민숙원사업 등 현황 조사
	③문제점 및 잠재력	·마을발전 저해 요인 · 문제점 분석을 통한 마을발전의 잠재자원 · 가능성 분석
2.기본구상	①정비목표 및 구현 전략의 설정	·마을발전의 종합적 측면에서 목표달성을 위한 구체적인 발전방향이나 전략제시
	②기본방향 및 지표설정	·마을의 중장기적인 발전의 구체적인 달성 가능한 지표 또는 목표지표를 정량적으로 제시
3.부문별계획	①마스터플랜 수립	·비전 및 발전반향에 근거하여 수립 ·주민이 공감할 수 있는 명확한 계획 수립
	②사업추진계획	·사업을 지속적으로 추진할 수 있는 주민 주도형 사업 추진계획 수립
	③단계별 시행계획	·연도별 추진방향과 주요 사업 계획 ·연도별 예산 및 집행계획, 행정 · 재정적 지원 계획
4.주민워크샵	①주민의견 수렴	·주민간담회 등을 통한 주민의견 수렴 ·주민의 내 · 외적 요구사항 파악 및 의견수렴
	②주민역량 강화	·마을주민의 역량강화 방안을 연구 · 기획 · 실행 ·마을 주민대상 공동체 교육실시
	③주민공동체 조직구성	·안정적인 관리 및 운영을 위한 마을공동체 조직을 구성 (마을규약, 조직구성 등)
	④마을공동체 프로그램 운영계획	·마을 수준에 맞는 우선순위 프로그램 발굴 ·마을 프로그램 운영을 위한 전문기술 및 운영 교육실시
	⑤사회경제적 재생방안	·지역특성에 맞는 마을사업 발굴 및 마을협동조합 운영 등 지역공동체사업 마련 검토

2-7 표준성과품

성과구분	표준성과도서			비 고
	구 분	규 격	제출부수	
관련도서	·지역자산 현황도 ·마스터플랜		1부 〃	
보고서	·보고서	발주자와 협의결정	발주자와 협의결정	

주 : ①제출부수 및 성과품 종류가 증가할 경우에는 증가배수에 해당하는 작업품과 비용을 가산한다.
②계획보고서 및 기타 관련자료의 규격 및 제출부수는 발주자와의 협의에 의하여 비용을 산정한다.

제5장 도시개발

제1절 도시개발구역 지정
제2절 환지방식 개발계획
제3절 주택단지 개발계획
제4절 산업단지 개발계획
제5절 「캠퍼스」계획
제6절 유통(물류)단지 개발계획

제1절 도시개발구역 지정

1-1 정 의

○ 도시개발구역 지정 신청업무라 함은 도시개발법에 의한 도시개발사업구역 지정과 관련하여 도시개발구역 지정(변경) 신청도서의 작성 및 구역지정(변경) 결과를 얻기 위하여 필요로 하는 제반 기술적 협의 업무를 말한다.

1-2 자료제공의 전제

○ 당해 도시개발구역 신청도서 작성에 필요한 모든 기초조사자료, 각종영향평가, 개발계획 관련자료 등은 원칙적으로 발주자가 제공하는 것으로 하되, 발주자가 보유하지 않는 자료는 엔지니어링사업자가 조사·수집한다.

○ 발주자가 제공하지 못하는 자료의 조사(교통량조사, 건물조사, 수목 및 산림조사, 도시시설물조사 등)에 있어서는 그 규모·내용에 의거하여 별도의 엔지니어링사업대가를 산정하여 엔지니어링사업자가 수행하며, 당해 관련자료의 기밀성과 광범위한 자료가 요구되는 경우 조사·분석에 필요한 상당기간과 자료수집비용이 전제되어야 한다.

1-3 업무범위와 추진과정

1-3-1 업무범위

○ 도시개발구역 지정(변경) 신청업무의 범위는 도시개발사업구역 지정(변경)을 필요로 하는 대상토지와 관련하여 지정(변경) 결과를 득하기 위하여 갖추어야할 제반 신청도서 가운에 엔지니어링사업자의 기술적 능력이 요구되는 부분의 작성 및 기술적 협의에 한정한다.

1-3-2 추진과정

○ 타부처(관계기관)와 협의나 전문가 자문 등에 소요되는 기간은 과업수행기간에서 제외하여 그 소요기간 만큼 과업수행기간을 연장하여야 한다.

1-4 품 산정의 원단위 산정과 기준

1-4-1 표준품 산정내역

○ 표준품 산정의 기준이 되는 비목은 제1장 총칙에서 제시한 비목을 중심으로 하였으며, 이는 도시개발구역지정(변경)에 필요한 사항만을 대상으로 한다.

○ 표준품 산정의 기준이 되는 직접인건비 품의 작업항목별 보할은 기존의 경험적 내용 및 항목별 업무의 난이도를 감안하여 설정토록 한다.

종 별		내 용	세부항목	단 위	비 고
직접비	직접인건비	1.계획검토	①관련법규 및 계획 검토 ②주변지역과의 상관성 검토	인·일 〃	
		2.도시개발구역지정(변경) 도서작성	①도시개발구역(변경)결정조서 ②도시개발구역 조사서 및 개발계획서 정리 ③각종 영향 검토서(별도) ④공고에 따른 의견내용 및 조치결과 작성 ⑤도시·군관리계획(변경)결정도 및 지형고시도면 작성 ⑥시설배치 및 토지이용계획 ⑦지적도 및 토지조서, 권리조서 작성 ⑧농지관련 서류작성(별도) ⑨산지, 초지관련 서류작성(별도)	〃 〃 〃 〃 〃 〃 〃 〃 〃	
		3.성과품 작성	①보고서작성 및 편집 ②관련도서작성	〃 〃	
		4.기술협의	①공청회/주민설명회 ②주민간담회/시민계획단 ③위원회심의 지원 ④관계기관 협의	〃 〃 〃 〃	
	직접경비	여비, 인쇄비, 조감도, 회의준비비, 현장 운영비 등		식	제1장 총칙참조
간접비	제경비	(직접인건비)×120%		〃	〃
	기술료	(직접인건비+제경비)×30%		〃	〃

1-4-2 산정 기준

1. 계획·기준면적의 설정

○ 기준면적은 해당사업의 법적규모제한 기준 및 민간개발 현황 등을 고려하여 10만㎡를 원칙으로 한다.

2. 표준품의 산정방법

○ 표준품의 적용에 있어 기준면적과 계획면적의 차이에 따른 품 산정은 아래의 수정식에 따라 기준면적의 소요작업량을 수정하여 산정한다.

○ 소요작업량 = 기준면적 소요작업량 × 면적보정계수(α)

3. 계획안의 수정과 과업중지에 따른 품 산정방법

○ 계획안이 작성되고 주민공람, 의회보고 등 행정절차과정을 거쳐 계획안이 확정된 후 발주자의 사정에 의하여 계획안이 일부변경·재작업이 수행되는 경우에는 그 변경·재작업의 정도에 따라 엔지니어링사업대가의 50~100% 수준에서 비용을 추가 지급하여야 한다.

○ 과업수행 중 발주자의 사정에 따른 과업 중단으로 인해 정부 회계연도가 경과되어 현저한 비용의 차이가 발생하였을 경우에는 엔지니어링사업대가를 당해 신년도의 노임단가를 기준으로 재산정하여야 한다.

1-4-3 단위별 변화수정과 보정

1. 면적의 대소에 대한 작업량 보정계수 산정

○ 계획 도시개발구역 면적이 기준면적을 초과하거나, 이에 못 미치는 경우의 직접인력 소요작업량의 산정을 위한 각 작업내용별 면적보정계수(α)는 다음과 같이 산정한다.

$$\alpha = [\frac{\text{계획면적}}{\text{기준면적}}]^{0.3} = (\frac{A}{10})^{0.3}$$

α = 면적보정계수
A = 계획면적(만㎡)

계획단위 면적별 보정계수

면적 (만㎡)	면적보정계수 (α)	면적 (만㎡)	면적보정계수 (α)
1.0	0.501	20.0	1.231
2.0	0.617	30.0	1.390
4.0	0.760	40.0	1.516
5.0	0.812	50.0	1.621
10.0	1.000	100.0	1.995

주 : 계획면적이 1만㎡미만인 경우에는 계획면적 1만㎡를 기준으로 하여 산정한다.

2. 직접인건비 소요 작업량 산정

○ 계획면적의 대소에 따른 직접인력 소요작업량의 산정방법은 아래와 같이 기준면적의 직능별 직접인력 소요작업량에 계획단위면적의 보정계수(α)를 곱하여 산출한다.

구 분	기준면적 (만㎡)	총작업량 (인·일)					
		기술사	특 급	고 급	중 급	초 급	보조원
도시개발구역지정 (변경)결정	10만㎡	4.0α	9.0α	25.4α	34.0α	77.2α	88.5α

1-5 표준단위 업무분류와 원단위

도시개발구역 지정(변경)결정 기술업무의 직능별 직접인력 소요작업량(10만㎡)

(단위 : 인·일/표준단위)

업무내용		표준단위	소요인력						비고
			기술사	특 급	고 급	중 급	초 급	보조원	
1.계획검토	①관련법규 및 계획 검토	10만㎡	0.4	0.6	1.2	1.8	3.0	3.5	
	②주변지역과의 상관성검토	10만㎡	0.2	0.4	0.8	1.2	2.0	2.5	
	소 계		0.6	1.0	2.0	3.0	5.0	6.0	
2.도시개발구역지정(변경)도서작성	①도시개발구역(변경)결정 조서	10만㎡	0.4	1.0	2.4	3.0	6.0	8.5	주1 주2
	②도시개발구역 조사서 및 개발계획서 정리	10만㎡	0.6	1.0	6.0	7.0	15.0	12.0	
	③각종 영향 검토서 정리	10만㎡	-	-	-	-	-	-	
	④공고에 따른 의견내용 및 조치결과 작성	10만㎡	0.6	0.6	1.2	2.0	3.0	4.5	
	⑤도시·군관리계획(변경)결정도 및 지형고시 도면작성	10만㎡	-	1.0	2.4	3.0	6.0	8.5	
	⑥시설배치 및 토지이용계획	10만㎡	0.4	1.0	2.4	3.0	6.0	8.5	
	⑦지적도 및 토지조서, 권리조서 작성	10만㎡	-	1.2	2.4	3.0	6.0	8.5	
	⑧농지관련 서류작성	10만㎡	-	-	-	-	-	-	
	⑨산지, 초지관련 서류작성	10만㎡	-	-	-	-	-	-	
	소 계		2.0	5.8	16.8	21.0	42.0	50.5	
3.성과품작성	①보고서작성 및 편집	10만㎡	0.7	1.1	3.3	5.0	15.1	16.0	
	②관련도서작성	10만㎡	0.7	1.1	3.3	5.0	15.1	16.0	
	소 계		1.4	2.2	6.6	10.0	30.2	32.0	
총 계			4.0	9.0	25.4	34.0	77.2	88.5	
4.기술협의	①공청회/주민설명회	1식	2.0	2.0	2.0	4.0	4.0	4.0	주3
	②주민간담회/시민계획단	1식	2.0	2.0	2.0	4.0	4.0	4.0	
	③위원회심의 지원	1식	2.0	2.0	2.0	4.0	4.0	4.0	
	④관계기관 협의	1식	2.0	2.0	2.0	4.0	4.0	4.0	
	소 계		8.0	8.0	8.0	16.0	16.0	16.0	

주 : ①변경(결정)도서작성에 필요한 개발(사업)계획 내용은 발주자측이 제공하며, 제공하지 못할 경우 별도의 엔지니어링업무로 산정한다.

②농지·산지전용협의, 각종영향성검토 및 각종영향평가업무는 별도의 엔지니어링활동업무로 계상한다. 토지적성평가 등은 별도 관련품을 적용한다.

③기술협의는 2회 이내 기준이며, 횟수가 늘어날 경우 증가배수에 해당하는 작업품과 비용을 가산한다. (필요항목 선택적 적용)

④측량, 토질조사 및 시험은 별도 관련품을 적용한다.

1-6 주요업무내용

구 분	항 목	내 용
1.계획검토	①관련법규 및 계획검토	·도시개발구역 지정(변경)에 필요한 관계법 및 상위 및 관련계획 검토
	②주변지역과의 상관성 검토	·당해 지역과 주변지역 관련사항
2.도시개발구역지정(변경)도서작성	①도시개발구역 결정(변경)조서	·도시개발구역 지정(변경) 신청에 따른 상세조서 작성
	②도시개발구역조사서 및 개발계획서 정리	·도시개발법 서식에 의한 내용 요약 작성
	③각종 영향서 정리	·도시개발법」에 따른 개발계획의 내용에 관한 서류 및 각종영향평가서 내용 검토·요약
	④공고에 따른 의견내용 및 조치결과 작성	·계획 공람공고시 제출된 의견에 대한 조치계획 작성 ·관련부서 협의의견에 대한 조치계획 작성
	⑤도시·군관리계획 결정(변경) 도서 작성	·위치도, 도시·군관리계획(변경)결정도 등 작성
	⑥시설배치 및 토지이용계획	·토지이용계획도 작성
	⑦지적도 및 토지조서, 권리조서 등 작성	·총괄표 및 세부조서로 구분 작성 ·총괄표는 행정구역 및 지목별로 구분 작성 ·토지면적 및 토지소유자의 동의에 관한 서류

1-7 표준성과품

성과구분	표준성과도서			비 고
	구 분	규 격	제출부수	
도시개발구역 지정(변경) 신청서류		1 식	3부	
각종도면	·도시·군관리계획 총괄도(위치도) ·도시·군관리계획(변경)결정도 ·개발계획도 ·지적도	1/25,000이상 1/25,000이상 1/1,200이상 1/5,000이상	1부 1부 1부 1부	
도시개발구역지정(변경)결정조서	·도시·군관리계획(변경)결정 조서 ·토지조서 ·농지조서 ·산지조서 ·초지조서		1부 1부 1부 1부 1부	

주 : ①제출부수 및 성과품 종류가 증가할 경우에는 증가배수에 해당하는 작업품과 비용을 가산한다.
②계획보고서 및 기타 관련자료의 규격 및 제출부수는 발주자와의 협의에 의하여 비용을 산정한다.

제2절 환지방식 개발계획

2-1 정 의

○ 환지방식이란 대지로써의 효용증진과 공공시설의 정비를 목적으로 실시할 토지의 교환, 분합, 기타 구획변경, 지목 또는 형질의 변경이나 공공시설의 설치, 변경에 관한 사업방식을 말한다.

2-2 자료제공의 전제

○ 당해 계획의 수립에 필요한 모든 관련자료는 원칙적으로 발주자가 제공하는 것으로 하되, 발주자가 보유하지 않는 자료는 엔지니어링사업자가 조사·수집한다.

○ 발주자가 제공되지 못하는 자료의 조사에 있어서는 그 규모·내용에 의거하여 별도의 엔지니어링사업대가를 산정하여 엔지니어링사업자가 수행하되, 당해 관련자료의 기밀성과 광범위한 자료가 요구될 경우에는 조사·분석에 필요한 상당기간과 자료수집비용이 전제되어야 한다.

2-3 업무범위와 추진과정

2-3-1 업무범위

○ 대지로써의 효용증진을 위하여 실시할 토지의 교환, 분합, 기타의 구획변경, 지목 또는 형질의 변경, 공공시설의 설치·변경

○ 본 사업과 병행하여 실시하는 건축물 기타의 공작물 또는 물건의 설치·관리 또는 처분에 관한 사업과 매립에 관한 사업

2-3-2 추진과정

○ 타부처(관계기관)와 협의나 전문가 자문 등에 소요되는 기간은 과업수행기간에서 제외하며, 그 소요기간 만큼 과업수행기간을 연장하여야 한다.

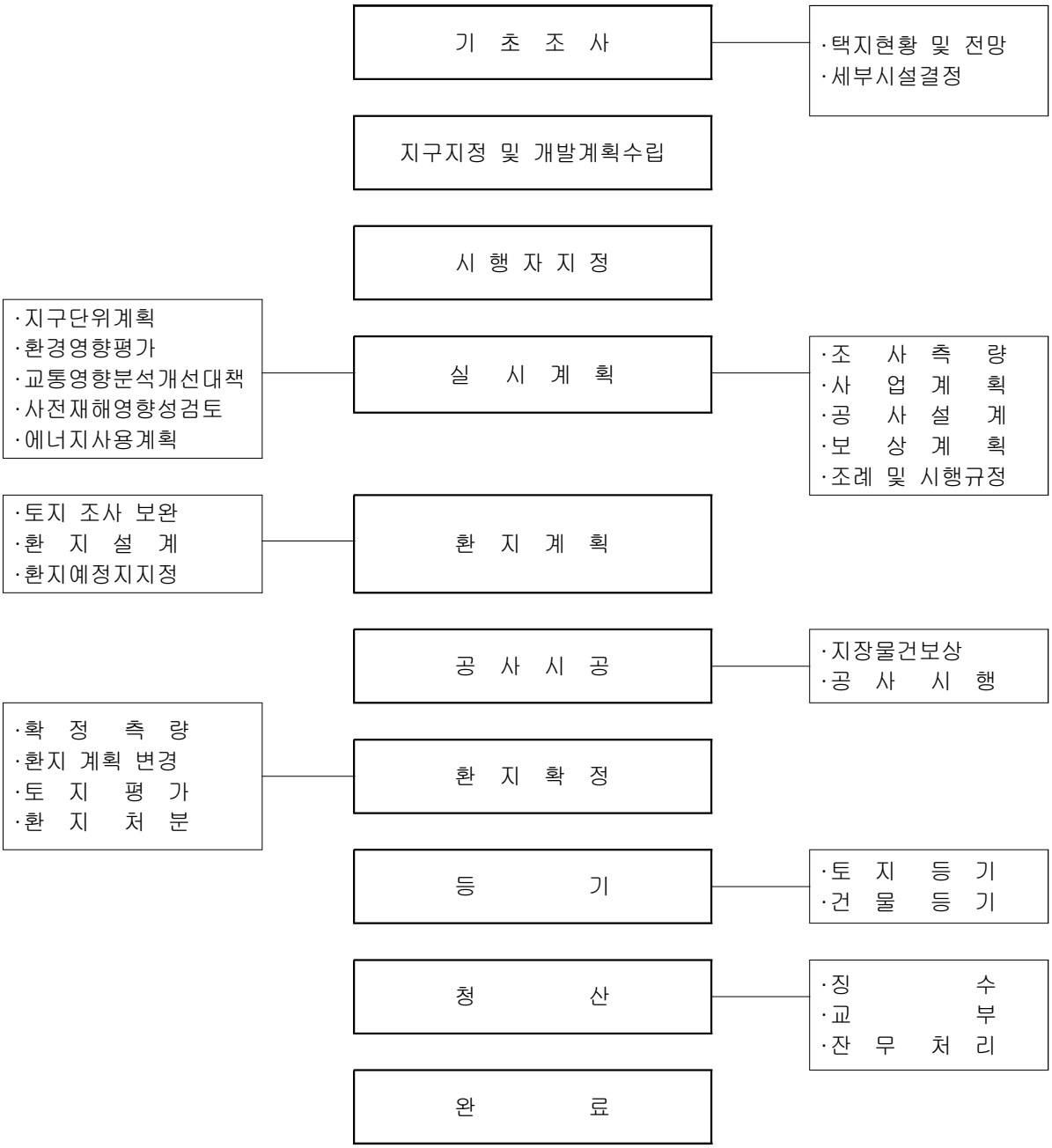

2-4 품 산정의 원단위 산정과 기준

2-4-1 표준품 산정내역

○ 표준품 산정의 기준이 되는 비목은 제1장 총칙에서 제시한 비목을 중심으로 하였으며, 이는 환지방식개발사업에 필요한 사항만을 대상으로 한다.

종 별		내 용		단 위	비 고
직접비	직접인건비	1.조 사	①토지 및 권리조사 ②도시시설조사	인·일 〃	
		2.측 량	①현황조사측량 ②계획측량 ③공사측량	식 〃 〃	
		3.사업계획	①기본계획 ②기본설계 ③자금계획 ④사업계획서 ⑤지구계 측량 ⑥계획도로중심점 및 가구계산	인·일 식 인·일 〃 〃 〃	공사비요율적용 지구계좌표계산
		4.설 계	①실시설계 ②공사측량 ③토질조사 및 시험	식 〃 〃	공사비요율적용 측량품적용 토질품적용
		5.보상계획	①유형보상	인·일	
		6.환지계획	①환지설계준비 ②토지평가 ③환지계산 ④환지할당 ⑤환지계획서 ⑥환지예정지지정측량	〃 〃 〃 〃 〃 〃	
		7.환지처분	①확정측량 ②환지처분서 ③감가보상	식 인·일 〃	측량품 적용
		8.등 기	①토지등기 ②건물등기	〃 〃	
		9.성과품 작성	①보고서작성 및 편집 ②관련도서 작성	〃 〃	
		10.기술협의	①공청회/주민설명회 ②주민간담회/시민계획단 ③위원회심의 지원 ④관계기관 협의	〃 〃 〃 〃	
	직접경비	여비, 인쇄비, 조감도, 회의준비비, 현장운영비 등		식	제1장 총칙참조
간접비	제경비	(직접인건비)×120%		〃	〃
	기술료	(직접인건비+제경비) ×30%		〃	〃

주 : 사업지구의 면적규모나 지역에 따라 지구단위계획, 에너지사용계획, 환경성 검토 또는 영향평가, 교통영향분석·개선대책, 사전재해영향성검토, 경관성검토, 공사시설을 위한 토질조사 및 시험 등의 제반계획, 평가, 조사, 시험 등은 별도의 엔지니어링 활동업무로 계상한다.

2-4-2 산정기준

1. 계획·기준면적 선정

○ 사업의 조사설계 산정의 원단위 책정의 기준을 마련하기 위하여 기준면적을 지구면적 10만㎡, 건물등기수 60호, 획지수 300(정리 전·후의 총획지수)으로 산정한다.

○ 계획면적은 환지방식사업으로 결정된 고시구역으로 한다.

2. 표준품의 산정방법

○ 표준품의 적용에 있어 기준면적과 계획면적의 차이에 따른 품 산정은 아래의 수정식에 따라 기준인구의 소요작업량을 수정하여 산정한다.

○ 소요작업량 = 기준면적소요작업량 × 면적보정계수(α, β, γ) × 밀도보정계수($\pi 1, \pi 2$)

○ 자료제공의 전제에 따라 업무에 필요한 자료의 발주자로부터 제공이 불가능하여 엔지니어링사업자에게 작성토록 할 경우 그의 내용에 따라 실비로 계상한다.

○ 업무의 수행에 필요한 지구단위계획, 각종 영향평가업무(교통, 환경, 재해), 에너지사용계획, 측량, 전산처리, 시험, 문화재조사, 농지전용협의 등의 경비에 대하여는 관련 품셈을 적용하되 품셈이 없는 분야는 실비로 가산한다.

○ 지구단위의 사업시행인가(고시)용 계획 및 건축배치계획을 중심으로 보다 상세한 계획이 요구될 때에는 업무의 범위로 보아 그 소요되는 작업량의 산정품은 토목설계의 경우 제5장 3절 주택단지개발계획에 준하며, 건축설계의 경우는 제4장 제1절 지구단위계획의 건축물에 관한 계획의 품을 준용한다.

3. 계획안의 수정과 과업중지에 따른 품 산정방법

○ 계획안이 작성되고 주민공람, 의회보고 등 행정절차과정을 거쳐 계획안이 확정된 후 발주자의 사정에 의하여 계획안이 일부변경·재작업이 수행되는 경우에는 그 변경·재작업의 정도에 따라 엔지니어링사업대가의 50～100% 수준에서 비용을 추가 지급하여야 한다.

○ 과업수행 중 발주자의 사정에 따른 과업 중단으로 인해 정부 회계연도가 경과되어 현저한 비용의 차이가 발생하였을 경우에는 엔지니어링사업대가를 당해 신년도의 노임단가를 기준으로 재산정하여야 한다.

2-4-3 단위별 변화수정과 보정

1. 작업량 보정계수 산정

1) 면적의 대소에 대한 작업량 보정계수 산정

○ 계획면적이 기준면적을 초과하거나 못 미치는 경우의 직접인력 소요작업량의 산정을 위한 각 작업내용별 보정계수(α, β, γ)는 다음과 같이 산정한다.

(1) 기본계획

$$\alpha = \left(\frac{\text{계획면적}}{\text{기준면적}}\right)^{0.6} = \left(\frac{A}{10}\right)^{0.6}$$

α = 보정계수
A = 계획면적(만㎡)

(2) 자금계획

$$\beta = \left(\frac{\text{계획면적}}{\text{기준면적}}\right)^{0.5} = \left(\frac{A}{10}\right)^{0.5}$$

β = 보정계수
A = 계획면적(만㎡)

(3) 기타 항목

$$\gamma = (0.075 \times \text{계획면적} + 0.25) = (0.075 \times A + 0.25)$$

γ = 보정계수
A = 계획면적(만㎡)

계획면적에 대한 작업량 보정계수

면적(만㎡)	보정계수		
	기본계획(α)	자금계획(β)	기타항목(γ)
3	0.486	0.548	0.475
5	0.660	0.707	0.625
10	1.000	1.000	1.000
20	1.516	1.414	1.750
30	1.933	1.732	2.500
50	2.627	2.236	4.000
100	3.981	3.162	7.750
200	6.034	4.472	15.250
300	7.696	5.477	22.750

주 : 계획면적이 3만㎡미만인 경우에는 계획면적 3만㎡를 기준으로 하여 산정한다.

2) 지구밀도의 변화에 따른 수정

(1) 사업지구 안의 건축물 등기수의 밀도변화에 따른 수정

$$\pi_1 = (0.82 + 0.003K_1)$$

$$K_1 = \frac{10}{A}K$$

π_1 = 보정계수
K = 지구내 총건물 등기수
K_1 = 10만㎡ 내 등기수
A = 계획면적(만㎡)

K_1	0	30	60	120	180	240	300	360	420
π_1	0.820	0.910	1.000	1.180	1.360	1.540	1.720	1.900	2.080

(2) 획지수의 밀도변화에 따른 수정

$$\pi_2 = (0.58 + 0.0014H_1)$$

$$H_1 = \frac{10}{A}H$$

π_2 = 보정계수
H = 정리전후의 지구내 총획지수
H_1 = 10h당 총획지수
A = 계획면적(만㎡)

H_1	100	200	300	400	500	600	700	800	900	1,000
π_2	0.720	0.860	1.000	1.140	1.280	1.420	1.560	1.700	1.840	1.980

2. 업무별 적용 보정계수

○ 업무별 적용 보정계수는 다음표와 같다.

업무별 적용 보정계수 일람표

업무분류		α	β	γ	π_1	π_2
조 사	①토지 및 권리조사 ②도시시설조사			○ ○		
사업계획	①기본계획 ②자금계획 ③사업계획서	○	○	○		
보상계획				○	○	
환지계획				○		○
환지처분				○		○
등 기	①토 지 ②건 물			○	○	○

주 : 2 개항 있을 때에는 곱한 보정계수를 적용한다.

2-5 표준단위 업무분류와 원단위

○ 표준지구(면적 10만㎡, 건물등기수 60, 필지수 300)의 표준단위 업무분류와 원단위를 단위별로 구성한다.

2-5-1 조 사

기술업무의 직능별직접인력 소요작업량(면적10만㎡,건물등기수60,필지수300기준)

(단위 : 인·일/표준단위)

구 분	업무내용	표준단위	소요인력						비고
			기술사	특급	고급	중급	초급	보조원	
1.토지 및 권리조사	①지적도 복사, 토지대장 및 등기부열람	10만㎡외	1.2	3.2	12.5	16.0	16.0	16.5	열람수수료 별도
	②도면작성	10만㎡외	0.3	0.8	3.0	5.0	7.0	7.0	
	소 계		1.5	4.0	15.5	21.0	23.0	23.5	
2.도시시설조사	①기본조사	10만㎡외	0.6	1.6	6.0	8.0	8.0	10.0	
	②교통관계조사	10만㎡외	0.3	0.8	3.0	4.0	4.0	4.0	
	③시설관계조사	10만㎡외	0.3	0.8	3.0	4.0	4.0	4.0	
	④조성관계조사	10만㎡외	0.3	0.8	3.0	4.0	4.0	4.0	
	⑤공급처리시설 관계조사	10만㎡외	0.6	1.6	4.0	8.0	10.0	10.0	
	⑥이전물건조사	10만㎡외	1.2	3.2	8.0	12.0	15.0	15.0	
	소 계		3.3	8.8	27.0	40.0	45.0	47.0	
계			4.8	12.8	42.5	61.0	68.0	70.5	

2-5-2 측 량

○ 환지방식사업의 현황조사측량, 계획측량, 공사측량에 대하여는 별도 산정한다.

2-5-3 사업계획

기술업무의 직능별직접인력 소요작업량(면적10만㎡,건물등기수60,필지수300기준)

(단위 : 인·일/표준단위)

구 분	업무내용	표준단위	소요인력						비 고
			기술사	특급	고급	중급	초급	보조원	
1.기본계획	①기본구상 ②계획조건의 검토 ③계 획 ④공정계획 ⑤경영계획	10만㎡외 10만㎡외 10만㎡외 10만㎡외 10만㎡외	6.0 4.0 6.0 1.5 1.5	9.6 6.4 9.6 2.4 2.4	15.0 10.0 20.0 3.0 3.0	18.0 15.0 25.0 4.0 4.0	18.0 15.0 30.0 4.0 4.0	18.0 15.0 30.0 4.0 4.0	
	소 계		19.0	30.4	51.0	66.0	71.0	71.0	
2.기본설계	엔지니어링사업대가의 기준 중 건설부문 공사비요율을 적용한다.								
3.자금계획	①사업비 개산(概算) ②수지계획	10만㎡외 10만㎡외	0.8 0.8	1.6 1.6	5.0 4.0	8.0 -	10.0 -	10.0 -	
	소 계		1.6	3.2	9.0	8.0	10.0	10.0	
4.사업계획서	①설계설명서 ②부속도서 ③인가신청서	10만㎡외 10만㎡외 10만㎡외	0.4 0.4 1.6	0.8 0.8 3.2	2.0 2.0 8.0	4.0 3.0 10.0	4.0 5.0 12.0	4.0 5.0 12.0	
	소 계		2.4	4.8	12.0	17.0	21.0	21.0	
5.측량	측량 대가기준 적용								
6.중심점 및 가구계산	측량 대가기준 적용(지구계 좌표계산/ 계획도로 중심점 및 가구계산)								

주 : 각종영향성검토 및 각종영향평가업무는 별도의 엔지니어링활동업무로 계상한다.

2-5-4 설 계

(단위 : 인·일/표준단위)

구 분	업무내용	소요인력						비고
		기술사	특급	고급	중급	초급	보조원	
1.실시설계	엔지니어링사업대가의 기준 중 건설부문 공사비요율을 적용한다.							
2.공사측량	측량용역대가기준 적용							
3.토질조사 및 시험	토질 및 기초조사 표준품셈과 시험비 별도 적용							

2-5-5 보상계획(유형보상)

기술업무의 직능별직접인력 소요작업량(면적10만㎡,건물등기수60,필지수300기준)

(단위 : 인·일/표준단위)

구 분	업무내용	표준단위	소요인력						비 고
			기술사	특급	고급	중급	초급	보조원	
유형보상	이전·이설보상물건조사	10만㎡외	6.0	12.0	18.0	36.0	36.0	36.0	감정료별도
	소 계		6.0	12.0	18.0	36.0	36.0	36.0	

주 : 제반 도시개발사업에 공통 적용

2-5-6 환지계획

기술업무의 직능별직접인력 소요작업량(면적10만㎡,건물등기수60,필지수300기준)

(단위 : 인·일/표준단위)

구 분	업무내용	표준단위	소요인력						비고
			기술사	특급	고급	중급	초급	보조원	
1.환지설계준비	①토지및권리조사보정 ②정리전토지지적의결정 ③환지설계기준의작성	10만㎡외 10만㎡외 10만㎡외	1.3 0.6 3.2	2.5 1.3 6.4	10.0 5.0 12.0	12.8 10.0 10.0	12.8 20.0 10.0	12.8 20.0 10.0	
	소 계		5.1	10.2	27.0	32.8	42.8	42.8	
2.토지평가	①정리전각필지평가 ②정리후각필지평가 ③증진율산정	10만㎡외 10만㎡외 10만㎡외	- 1.2 0.8	- 2.4 1.6	- 5.0 4.0	- 8.0 4.0	- 12.0 8.0	- 12.0 8.0	감정료 별도
	소 계		2.0	4.0	9.0	12.0	20.0	20.0	
3.환지계산 3-1 비례평가식 환지계산	①비례율산정 ②권리지수산정 ③환지지적산출	10만㎡외 10만㎡외 10만㎡외	1.6 0.8 0.8	3.2 1.6 1.6	10.0 4.0 4.0	12.0 8.0 8.0	15.0 8.0 8.0	15.0 8.0 8.0	
	소 계		3.2	6.4	18.0	28.0	31.0	31.0	
3-2 절충식 환지계산	①비례율산정 ②공통부담율산정 ③권리지수산정 ④잠정환지지적 ⑤증가배당율의 산정 ⑥잠정환지평가	10만㎡외 10만㎡외 10만㎡외 10만㎡외 10만㎡외 10만㎡외	1.6 0.8 0.8 0.8 0.8 0.8	3.2 1.6 1.6 1.6 1.6 1.6	10.0 4.0 4.0 4.0 4.0 4.0	15.0 8.0 8.0 8.0 6.0 6.0	15.0 8.0 8.0 8.0 6.0 6.0	15.0 8.0 8.0 8.0 6.0 6.0	
	소 계		5.6	11.2	30.0	51.0	51.0	51.0	
3-3 면적식 환지계산	①공통부담율산정 ②급지별공통부담율계산 ③환지지적산출	10만㎡외 10만㎡외 10만㎡외	0.8 1.6 0.8	1.6 3.2 1.6	4.0 10.0 4.0	6.0 15.0 6.0	8.0 20.0 8.0	8.0 20.0 8.0	
	소 계		3.2	6.4	18.0	27.0	36.0	36.0	
4.환지할당	①가할당 ②환지할당 ③가구별환지조서 ④공람에따른 환지계산의 보완 ⑤환지원안설명 ⑥환지예정지검토및조서	10만㎡외 10만㎡외 10만㎡외 10만㎡외 10만㎡외 10만㎡외	3.2 4.8 - 2.4 1.2 0.8	6.4 9.6 - 4.8 2.4 1.6	10.0 22.0 - 10.0 4.0 8.0	12.0 25.0 10.0 15.0 4.0 20.0	12.0 35.0 10.0 20.0 4.0 30.0	12.0 35.0 10.0 20.0 - 40.0	면적식 제외
	소 계		12.4	24.8	54.0	86.0	111.0	117.0	평가식 및 절충식
			9.2	18.4	44.0	74.0	99.0	105.0	면적식
5.환지계획서	인가신청서		4.0	8.0	15.0	20.0	30.0	45.0	
6.환지예정지 지정 측량	측량용역대가기준 적용								

2-5-7 환지처분

기술업무의 직능별직접인력 소요작업량(면적10만㎡,건물등기수60,필지수300기준)

(단위 : 인·일/표준단위)

구 분	업무내용	표준단위	소요인력						비고
			기술사	특급	고급	중급	초급	보조원	
1.확정측량	확정측량		측량품 별도 적용						
2.환지 처분서	①토지및권리조사보정	10만㎡외	1.3	2.6	10.0	12.8	12.8	12.8	
	②환지계획변경	10만㎡외	8.8	17.6	40.0	50.0	60.0	60.0	
	③청산금산정	10만㎡외	0.8	1.6	3.0	15.0	22.0	22.0	
	④환지처분첨부도	10만㎡외	0.2	0.4	1.0	2.0	8.0	8.0	
	⑤공공시설용으로제공될토지조사	10만㎡외	0.4	0.8	1.0	2.0	4.0	8.0	
	⑥인가신청서	10만㎡외	4.0	8.0	15.0	20.0	30.0	45.0	
	소 계		15.5	31.0	70.0	101.8	136.8	155.8	
3.감가보상	①자료조사	10만㎡외	0.2	0.4	0.5	2.0	3.0	1.0	
	②증진율산정	10만㎡외	0.4	0.8	2.0	2.0	2.0	2.0	
	③감가보상금산정	10만㎡외	0.2	0.2	-	3.0	-	-	
	소 계		0.8	1.4	2.5	7.0	5.0	3.0	

2-5-8 등기

기술업무의 직능별직접인력 소요작업량(면적10만㎡,건물등기수60,필지수300기준)

(단위 : 인·일/표준단위)

구 분	업무내용	표준단위	소요인력						비 고
			기술사	특급	고급	중급	초급	보조원	
1.토지등기	①토지등기촉탁서 또는 신청서작성	10만㎡외	0.8	2.0	2.4	9.3	10.9	18.0	열람수수료별도
	②부동산등기부조사정리	10만㎡외	1.0	2.6	10.0	12.8	12.8	12.8	
	③토지대위등기	10만㎡외	1.5	4.0	12.0	35.0	50.0	50.0	
	소 계		3.3	8.6	24.4	57.1	73.7	80.8	
2.건물등기	①건물소재조사	10만㎡외	0.1	0.3	2.0	10.4	19.6	19.6	
	②건물등기촉탁서 또는 신청서작성	10만㎡외	0.4	1.0	2.4	7.2	11.6	11.6	
	소 계		0.5	1.3	4.4	17.6	31.2	31.2	

2-5-9 성과품작성

기술업무의 직능별직접인력 소요작업량(면적10만㎡,건물등기수60,필지수300기준)

(단위 : 인·일/표준단위)

구 분	업무내용	표준단위	소요인력						비 고
			기술사	특급	고급	중급	초급	보조원	
성과품작성	①보고서작성 및 편집	10만㎡외	0.7	2.3	5.1	4.3	7.7	5.6	
	②관련도서작성	10만㎡외	0.3	1.1	2.6	2.9	10.0	13.9	
	소 계		1.0	3.4	7.7	7.2	17.7	19.5	

2-5-10 기술협의

기술업무의 직능별직접인력 소요작업량(면적10만㎡,건물등기수60,필지수300기준)

(단위 : 인·일/표준단위)

구 분	업무내용	표준 단위	소요인력						비 고
			기술사	특급	고급	중급	초급	보조원	
성과품작성	①공청회/주민설명회	1식	2.0	2.0	2.0	4.0	4.0	4.0	
	②주민간담회/시민계획단	1식	2.0	2.0	2.0	4.0	4.0	4.0	
	③위원회 심의 지원	1식	2.0	2.0	2.0	4.0	4.0	4.0	
	④관계기관 협의	1식	2.0	2.0	2.0	4.0	4.0	4.0	
	소 계		8.0	8.0	8.0	16.0	16.0	16.0	

주 : 기술협의는 2회 이내 기준이며, 횟수가 늘어날 경우 증가배수에 해당하는 작업품과 비용을 가산한다. (필요항목 선택적 적용)

2-6 주요업무내용

2-6-1 조 사

구 분	업무내용	내 용
1.토지 및 권리조사	①지적도복사, 토지대장 및 등기부열람	·지적도복사 ·토지대장열람 ·토지등기부열람 ·토지대장작성 및 집계 ·소유자별 토지조서 및 목록작성
	②도면작성	·지적종합도작성
2.도시시설조사	①기본조사	·상위계획·도시계획사항조사 ·인구현황조사 ·교통조건조사 ·공급처리조건조사 ·환경정비수준조사 ·토지이용현황조사
	②교통관계조사	·도로현황과 장래계획조사 ·교통시설현황과 장래계획조사
	③시설관계조사	·교육시설 조사 ·상업시설 조사 ·공원 및 식생조사
	④조성관계조사	·지구와 주변의 재해조사 ·관계법규조사
	⑤공급처리시설관계조사	·상하수도 시설조사 ·전력, 통신 시설조사 ·하천, 수로 시설조사
	⑥이전물건조사	·요(要)이전, 이설물건의 조사 ·이전물건위치도

2-6-2 사업계획

구 분	업무내용	내 용
1.기본계획	①기본구상	·사업의 기본구상 ·재원확보의 방침 ·환지설계의 방침 ·공사의 방침 ·사업기간
	②계획조건의 검토	·지역 지구와 택지규모의 검토 ·도시시설과의 관련검토 ·배수 및 하수처리방식의 검토 ·주변과의 관계검토
	③계 획	·토지이용계획 ·도로계획 ·인구수용계획 ·주택계획 ·공공시설계획 ·공원녹지계획, 환경보전계획
	④공정계획	·행정처리사항의 기간 ·관계부처와의 일정조정 ·공정계획표
	⑤경영계획	·사업비개산액(槪算額)과 재원의 조정 ·감보율과 공사비 및 체비지의 조정
2.기본설계		
3.자금계획	①사업비개산(槪算)	·공사비 개산(槪算) ·보상비 개산(槪算) ·사무비 개산(槪算)
	②수지계획	·재원별 수입·지출 조정 ·수지계획서 작성 ·연도별 세입세출 자금계획
4.사업계획서	①설계설명서	·공공시설별조서 ·정리전후의 면적대조표 ·사업설명서
	②부속도서	·부속도 작성 ·시행조례, 정관, 규정안의 작성
	③인가신청서	·인가신청서 작성

2-6-3 보상계획(유형보상)

구 분	업무내용	내 용
유형보상	이전·이설보상 물건조사	·현지조사 ·공작물자료작성 ·가옥 평면도작성 ·이전·이설관계보상비 개산(槪算)

2-6-4 환지계획

구 분	업무내용	내 용
1.환지설계준비	①토지 및 권리조사 보정	·토지등기부열람 및 조서작성 ·소유자별 목록보완 ·동별, 지목별 집계수정, 지적도 수정
	②정리전토지지적의 결정	·지구계의 검토 및 필지별 면적 구적 ·지구계면적 정정률의 산정 및 지적의 결정
	③환지설계기준의 작성	·자료조사 및 기준안작성
2.토지평가	①정리전각필지평가	·각필지평가계산
	②정리후각필지평가	·가구평가계산
	③증진율산정	·정리전 총평가지수 계산 ·정리후 총평가지수 계산
3.환지계산 3-1.비례평가식 환지계산	①비례율산정	·비례율계산
	②권리지수산정	·권리지수계산
	③환지지적산출	·환지지적계산
3-2.절충식 환지계산	①비례율산정평가	·비례율계산
	②공통부담률계산	·연도(沿道)부담지적의 계산 ·공통부담률의 계산
	③권리지수산정	·권리지수계산
	④잠정환지지적	·잠정환지지적의 계산
	⑤증가배당률의 산정	·증가배당률계산
	⑥잠정환지의 평가	·평가계산 및 집계
3-3.면적식 환지계산	①공통부담률계산	·가산(加算)지적의 계산 ·연도(沿道)부담지적의 계산 ·연도(沿道)부담률 계산 ·공통부담률의 계산
	②급지별(級地別) 공통부담률 계산	·급지(級地)별 필지면적 또는 지수계산 ·사업비부담지수산출 ·급지별 공통부담률계산
	③환지지적산출	·환지지적의 계산 및 집계
4.환지할당	①가할당(假割當) (면적식제외)	·가할당계산
	②환지할당	·할당용 도면 작성 ·각필지감보율의 계산 및 검토 ·평가계산용(급지별) 도면 작성 ·지수계산 및 청산지수산출(권리면적 및 과부족계산) ·평가조서 작성(급지별조서) ·할당오차의 검토
	③가구(街區)별 환지조서	·가구(街區)별 획지(劃地)별조서
	④공람에 따른 환지계산의 보완	·환지계산보완
	⑤환지원안 설명	·가환지 원안설명
	⑥환지예정지 검토	·환지지정지검토 및 조서작성
5.환지계획서	인가신청서	·첨부서류의 수집 ·환지도의 트레스와 축도 ·체비지 기타특별지 명세서 ·각필지, 각권리별청산(과부족면적) ·환지계획총괄표

2-6-5 환지처분

구 분	업무내용	내 용
6.환지처분서	①토지 및 권리조사 보정	·등기부열람 ·토지대장열람 ·지목별 집계수정 및 소유자별 목록보완 ·지적도수정
	②환지계획의 변경	·환지계산변경 ·환지명세서변경 ·환지도 수정
	③청산금 산정	·청산액의 계산 및 집계
	④환지처분첨부도	·환지처분도 작성
	⑤공공시설용으로 제공될 토지조서	·공공시설용으로 제공될 토지의 도서
	⑥인가신청서	·환지처분명세서 ·보유지 기타특별지 명세서 ·권리별청산금 명세서
7.감가보상	①자료조사	·대상시설 보완조사(현지조사 포함) ·대상여건도 작성
	②증진율 산정	·정리전 총평가지수 보정 ·정리후 총평가지수 보정 ·검토 및 계산
	③감가보상금산정	·감가율의 산정

2-6-6 등 기

구 분	업무내용	내 용
1.토지등기	①토지등기촉탁서 또는 신청서 작성	·환지명세서 작성 ·등기촉탁서 또는 신청서 2본 작성
	②부동산등기조사정리	·토지 및 등기부열람서
	②토지대위등기	·성명, 주소 정정, 분필조사 및 정정 ·분필에 따른 지구외토지의 등기 촉탁서 또는 신청서작성
2.건물등기	①건물소재조사	·청산액의 계산 및 집계
	②건물등기촉탁서 또는 신청서 작성	·신청서 1식

2-6-7 성과품작성

구 분	업무내용	내 용
성과품작성	①보고서작성 및 편집	·도시개발사업 관련보고 작성 및 편집
	②관련도서 작성	·도시개발사업 관련 부속도서 작성

2-7 표준성과품

2-7-1 조 사

업무구분	성과항목	표준성과도서					
		도면	원본	사본	서류	원본	사본
1.토지 및 권리조사	①지적도복사, 토지대장 및 등기부열람	지적도복사	1	1	·토지대장및등기부 등 열람서 ·토지조서 ·소유자별조서	1 1 1	
	②도면작성	지적종합도	1				
2.도시시설조사	①기본조사				·도시시설 조사서	1	
	②교통관계조사						
	③시설관계조사						
	④조성관계조사						
	⑤공급처리시설 관계조사	공급처리시설 현황도	1				
	⑥이전물건조사	이전물건 위치도	1		·이전물건개산조서 ·이전물건 총괄표	1 1	

주 : 제출부수 및 성과품 종류가 증가할 경우에는 증가배수에 해당하는 작업품과 비용을 가산한다.

2-7-2 사업계획

업무구분	성과항목	표준성과도서					
		도면	원본	사본	서류	원본	사본
3.기본계획*	①기본구상	기본구상도	1				
	②기본조건의 검토정리						
	③계 획	기본계획도	1		기본계획서	1	
	④공정계획				공정설계표	1	
	⑤경영계획				계 획 서	1	
4.자금계획	①사업비개산(概算)				사업비개산 조서	1	5
	②수지계획				자금계획서	1	5
5.사업계획서	①설계설명서				설계설명서	1	
	②부속도서	첨부도 1식	1	5	조례, 규정		5
	③인가신청서			5	인가신청서		5

주 : 제출부수 및 성과품 종류가 증가할 경우에는 증가배수에 해당하는 작업품과 비용을 가산한다.
* 도시시설조사 및 기본계획 성과도서는 별도계획 보고서가 있을때는 보고서로 대체

2-7-3 보상계획(유형보상)

업무구분	성과항목	표준성과도서					
		도면	원본	사본	서류	원본	사본
6.유형보상	이전, 이설 보상물건조사	가옥평면도	1		관계서류	1	

주 : 제출부수 및 성과품 종류가 증가할 경우에는 증가배수에 해당하는 작업품과 비용을 가산한다.

2-7-4 환지계획

업무구분	성과항목	표준성과도서						비고
		도면	원본	사본	서류	원본	사본	
7.환지설계준비	①토지 및 권리조사보정	수정지적도	1		토지조서	1		
	②정리전토지지적의결정	지구계분할도	1					
	③환지설계기준의 작성				환지설계기준안	1		
8.가구(街區)평가	①정리후가구평가	가구평가도	1	1	가구평가계산서	1		
	②증진율산정				증진율계산서	1		
9.환지계산 ①비례평가식 환지계산	①비례율산정				비례율계산서	1		
	②권리지수산정							
	③환지지적산출							
②절충식 환지계산	①비례율산정	연도부담계획도	1		비례율계산서	1		
	②공통부담률산정	공통부담계산도	1		공통부담계산서	1		
	③권리지정산정				권리지수계산서	1		
	④잠정환지지적							
	⑤증가배당률산정				증가배당율계산서	1		
	⑥잠정환지의 평가							
③면적식 환지계산	①공통부담률계산	가산지적계산도 연도부담계산도	1 1		가산지적계산서 연도부담계산서 공통부담계산서	1 1 1		
	②급지별공통부담률계산	급지별구분도	1		급지별지적조사 급지별공통부담율계산서	1 1		
	③환지지적산출							
10.환지할당	①가할당(假割當)							면적식 제외
	②환지할당	할당도	1		할당계산서	1		
	③가구별환지조서				가구별획지조서	1		
	④공람에따른환지계산의 수정							
	⑤환지원안설명							
	⑥환지예정지검토 및 보완							
11.환지계획서	인가신청서	환지도	1		인가신청서 1식	1		

주 : 제출부수 및 성과품 종류가 증가할 경우에는 증가배수에 해당하는 작업품과 비용을 가산한다.

2-7-5 환지처분

업무구분	성과항목	표준성과도서					
		도면	원본	사본	서류	원본	사본
12.환지처분서	①토지 및 권리조사 보정	지적도	1		토지조서	1	
	②환지계산의 변경	환지변경도	1		환지변경서	1	
	③청산금산정	지적도	1		청산금조서	1	
	④환지처분첨부도	첨부도 1식	1		토지조서	1	
	⑤공공시설용으로 제공될 토지조서	도 면	1		조 서	1	
	⑥인가신청서	환지확정도		5	인가신청서 1식		5
13.감가보상	①자료조사	대상시설도	1	1			
	②증진율 산정				증진율계산서	1	
	③감가보상금산정				감가보상금조서	1	

주 : 제출부수 및 성과품 종류가 증가할 경우에는 증가배수에 해당하는 작업품과 비용을 가산한다.

2-7-6 등 기

업무구분	성과항목	표준성과도서					
		도면	원본	사본	서류	원본	사본
14.토지등기	①토지등기촉탁서 또는 신청서 작성				신청서 1식	1	
	②부동산등기부 조사정리	지적도	1		토지조서	1	
	③토지대위등기				신청서 1식	5	
15.건물등기	①건물소재도	건물소재도	1				
	②건물등기촉탁서 또는 신청서 작성				신청서 1식	5	

주 : ①제출부수 및 성과품 종류가 증가할 경우에는 증가배수에 해당하는 작업품과 비용을 가산한다.
②본표준성과품은 업무구분에 따른 것이므로 연속작업일 때에는 성과도서를 전작업의 성과품으로 한다. 또한 모든 성과품을 CD로 납품할 수 있다.

제3절 주택단지 개발계획

3-1 정 의

○ 주택단지개발계획이란 국민주거생활의 안정과 복지향상에 기여할 목적으로 일단의 주택단지 조성을 위하여 주택건설용지를 개발공급하는 업무를 말하며, 지목 또는 토지의 형질변경이나 공공시설의 설치변경 등 주거환경에 관한 일단의 토지개발사업에 관한 계획을 말한다.

3-2 자료제공의 전제

○ 주택단지개발계획에 필요한 모든 관련자료는 원칙적으로 발주자가 제공하는 것으로 하되, 발주자가 보유하지 않는 자료는 엔지니어링사업자가 조사·수집한다.

○ 발주자가 제공하지 못하는 자료의 조사에 있어서는 그 규모·내용에 의거하여 별도의 엔지니어링사업대가를 산정하여 엔지니어링사업자가 수행하며 당해 자료의 기밀성과 광범위한 자료가 요구될 경우에는 조사·분석에 필요한 상당기관과 자료수집비용이 전제되어야 한다.

3-3 업무범위와 추진과정

3-3-1 업무범위

○ 주택단지개발계획의 업무범위는 기본계획, 기본설계, 실시설계 등을 엔지니어링활동의 주범위로 한다.

3-3-2 추진과정

○ 타부처(관계기관)와 협의나 전문가 자문 등에 소요되는 기간은 과업수행기간에서 제외하여 그 소요기간만큼 과업수행기간을 연장하여야 한다.

1. 계획수립 추진과정

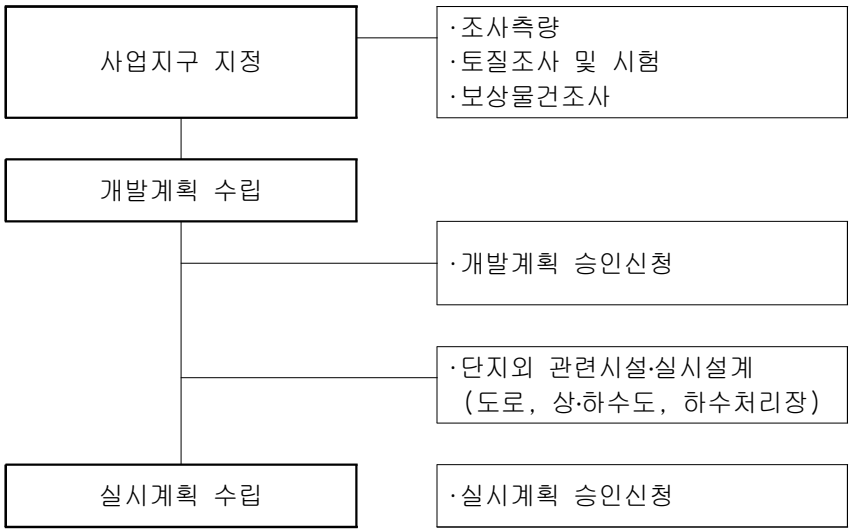

2. 과업수행 추진과정

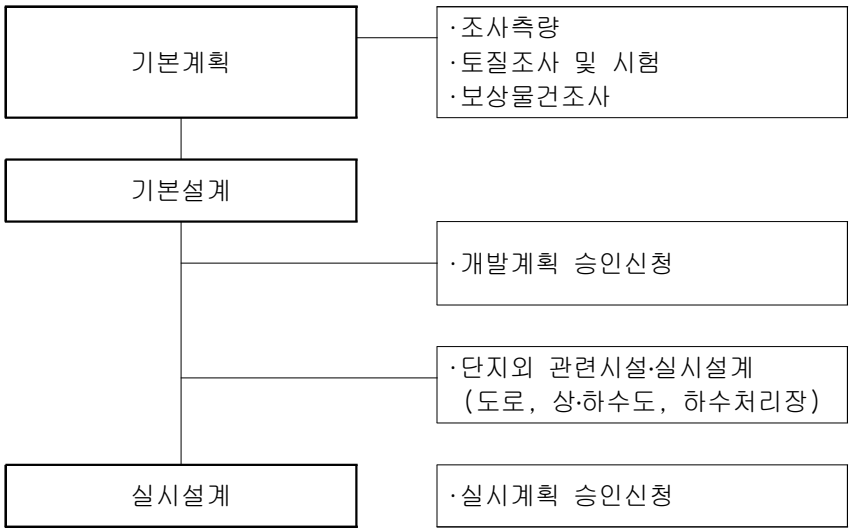

3-4 품 산정의 원단위 산정과 기준

3-4-1 표준품 산정내역

○ 표준품 산정의 기준이 되는 비목은 제1장 총칙에서 제시한 비목을 중심으로 하였으며, 이는 주택단지개발계획에 필요한 사항만을 대상으로 한다.

○ 표준품 산정의 기본이 되는 직접인건비 품의 작업항목별 보할은 업무의 난이도를 감안하여 설정토록 한다.

종 별		내 용		단 위	비 고
직접비	직접인건비	1.기본계획	①현황조사 및 분석 ②개발정비조건 및 계획내용설정 ③구상안 작성 ④인구수용 및 생활권계획 ⑤주택계획 ⑥공공시설계획 ⑦토지이용계획 ⑧교통계획 ⑨공급처리시설계획 ⑩집단에너지 공급계획 ⑪공원녹지계획 ⑫경관 및 미관계획 ⑬친환경계획 ⑭택지공급계획 ⑮재원조달 및 자금투자계획 ⑯운영관리계획 ⑰인·허가 승인도서 작성	인·일 〃 〃 〃 〃 〃 〃 〃 〃 〃 〃 〃 〃 〃 〃 〃	
		2.성과품작성	①보고서작성 및 편집 ②관련도서 작성	〃 〃	
		3.기술협의	①공청회/주민설명회 ②주민간담회/시민계획단 ③위원회심의 지원 ④관계기관 협의	〃 〃 〃 〃	
		4.조사측량	측량품 별도적용		
		5.토질조사 및 시험	토질조사 및 시험품 별도적용		
		6.기본설계	엔지니어링사업대가의 기준 중 건설부문공사비 요율을 적용		
		7.실시설계	엔지니어링사업대가의 기준 중 건설부문공사비 요율을 적용		
		8.실시계획	기본계획, 성과품작성, 기술협의 업무내용 중 실시계획 관련 항목만 적용		
	직접경비	여비, 인쇄비, 조감도, 회의준비비, 현장운영비 등		식	제1장 총칙참조
간접비	제경비	(직접인건비)×120%		〃	〃
	기술료	(직접인건비+제경비) ×30%		〃	〃

주 : 주택단지개발사업에 관련되는 부수적인 업무인 조사측량, 개발타당성, 토질조사 및 시험, 보상물건(유형보상)조사, 단지외의 인입시설, 하수처리장 설계 등과 같은 업무와 지구단위계획, 각종영향성검토 및 각종영향평가업무는 별도의 엔지니어링활동업무로 계상한다.

3-4-2 산정기준

1. 계획·기준면적의 설정

○ 기준면적은 50만㎡로 하였으며, 직능별 직접인력 소요원단위는 기 작성된 주택단지계획 등의 투입기술자 비율을 감안하여 설정하였다.

○ 계획면적은 주택단지개발계획의 지정 또는 과업면적을 원칙으로 한다.

2. 표준품의 산정방법

○ 표준품의 적용에 있어 기준면적과 계획면적의 차이에 따른 품 산정은 아래의 수정식에 따라 기준면적의 소요작업량을 수정하여 산정한다.

○ 소요작업량 = 기준면적소요작업량× 면적보정계수(α)× 과업밀도보정계수(β)

3. 계획안의 수정과 과업중지 등에 따른 산정방법

○ 계획안이 작성되고 주민공람, 의회보고 등 행정절차과정을 거쳐 계획안이 확정된 후 발주자의 사정에 의하여 계획안이 일부변경·재작업이 수행되는 경우에는 그 변경·재작업의 정도에 따라 엔지니어링사업대가의 50～100% 수준에서 비용을 추가 지급하여야 한다.

○ 과업수행 중 발주자의 사정에 따른 과업 중단으로 인해 정부 회계연도가 경과되어 현저한 비용의 차이가 발생하였을 경우에는 엔지니어링사업대가를 당해 신년도의 노임단가를 기준으로 재산정하여야 한다.

3-4-3 단위별 변화수정과 보정

1. 작업량 보정계수 산정

1) 면적의 대소에 대한 작업량 보정계수 산정

○ 계획면적이 기준면적을 초과하거나 못 미치는 경우의 직접인력 소요작업량의 산정을 위한 면적보정계수(α)는 다음의 식에 의해 산정한다.

$$\alpha = \left(\frac{\text{계획면적}}{\text{기준면적}}\right)^{0.6} = \left(\frac{A}{50}\right)^{0.6}$$

α = 면적보정계수
A = 계획면적(만㎡)

계획단위 면적별 보정계수

면 적 (만㎡)	보정계수 (α)	면 적 (만㎡)	보정계수 (α)
3	0.185	70	1.224
10	0.381	100	1.516
20	0.577	150	1.933
30	0.736	200	2.297
50	1.000	300	2.930

주 : 계획면적이 3만㎡미만인 경우에는 계획면적 3만㎡를 기준으로 하여 산정한다.

2) 지구밀도의 변화에 따른 수정

○ 지형의 복잡성, 계획건축물의 밀도정도, 과업축척의 대소에 의한 표준품의 조정은 다음과 같다.

계획단위 밀도별 보정계수

구 분	과업조건의 정도	보정계수(β)
기본계획	대상조건이 복잡한 경우	1.0 ~ 1.25
	구상안 대안작성의 수량	0.8 ~ 1.5

2. 직접인건비 소요 작업량 산정

○ 계획면적의 대소에 따른 직접인력 소요작업량의 산정방법은 아래와 같이 기준면적의 직능별 직접인력 소요작업량에 계획단위 보정계수(α, β)을 곱하여 산출한다.

구 분	기준면적 (만㎡)	총작업량(인·일)					
		기술사	특 급	고 급	중 급	초 급	보조원
기본계획	50	15.2αβ	27.3αβ	89.3αβ	95.1αβ	213.2αβ	262.9αβ

3-5 표준단위 업무분류와 원단위

3-5-1 기본계획

기술업무의 직능별 직접인력 소요작업량(면적 50만㎡ 기준)

(단위 : 인·일/표준단위)

구 분	업무내용	표준단위	소요인력						비고
			기술사	특급	고급	중급	초급	보조원	
1.기본계획	①현황조사 및 분석	50만㎡	0.8	3.2	5.6	7.9	16.2	16.2	
	②개발정비조건 및 계획내용 설정	50만㎡	0.9	2.7	5.1	7.3	7.3	10.9	
	③구상안 작성	50만㎡	1.6	2.0	5.1	6.5	14.5	14.5	
	④인구수용 및 생활권계획	50만㎡	0.9	0.9	2.6	2.5	6.6	8.7	
	⑤주택계획	50만㎡	0.7	1.1	5.3	5.3	8.8	13.2	
	⑥공공시설계획	50만㎡	0.7	1.1	5.3	5.3	8.8	13.2	
	⑦토지이용계획	50만㎡	1.5	1.6	9.0	9.8	32.5	32.5	
	⑧교통계획	50만㎡	1.0	0.6	4.8	4.8	14.5	19.8	
	⑨공급처리시설계획	50만㎡	1.3	1.6	7.4	7.4	14.9	14.9	
	⑩집단에너지 공급계획	50만㎡	0.7	0.9	2.8	2.6	6.2	10.2	
	⑪공원녹지계획	50만㎡	0.6	1.0	4.8	4.8	7.9	11.9	
	⑫경관 및 미관계획	50만㎡	0.6	1.2	4.0	3.6	8.4	14.5	
	⑬친환경계획	50만㎡	0.6	1.2	4.0	3.3	11.0	14.5	
	⑭택지공급계획	50만㎡	0.5	1.0	3.0	3.0	6.7	11.3	
	⑮재원조달 및 자금투자계획	50만㎡	0.3	2.0	7.5	7.1	15.8	16.9	
	⑯운영관리계획	50만㎡	0.3	1.0	2.6	4.0	6.6	9.9	
	⑰인·허가 승인도서 작성	50만㎡	1.2	0.8	2.7	2.7	8.8	10.3	
	소 계		14.2	23.9	81.6	87.9	195.5	243.4	
2.성과품작성	①보고서작성 및 편집	50만㎡	0.7	2.3	5.1	4.3	7.7	5.6	
	②관련도서 작성	50만㎡	0.3	1.1	2.6	2.9	10.0	13.9	
	소 계		1.0	3.4	7.7	7.2	17.7	19.5	
총 계			15.2	27.3	89.3	95.1	213.2	262.9	
3.기술협의	①공청회/주민설명회	1식	2.0	2.0	2.0	4.0	4.0	4.0	주1
	②주민간담회/시민계획단	1식	2.0	2.0	2.0	4.0	4.0	4.0	
	③위원회심의 지원	1식	2.0	2.0	2.0	4.0	4.0	4.0	
	④관계기관 협의	1식	2.0	2.0	2.0	4.0	4.0	4.0	
	소 계		8.0	8.0	8.0	16.0	16.0	16.0	

주 : ①기술협의는 2회 이내 기준이며, 횟수가 늘어날 경우 증가배수에 해당하는 작업품과 비용을 가산한다. (필요항목 선택적 적용).

②보상물건조사업무를 포함하여 시행할 경우 직접인건비 산정방법은 제2절 환지방식개발계획의 보상계획(유형보상) 2-5-5를 준용한다.

③각종영향성검토 및 각종영향평가업무는 별도의 엔지니어링활동업무로 계상한다.

3-5-2 조사측량

○ 측량품을 별도 적용한다.

3-5-3 토질조사 및 시험

○ 토질조사 및 시험품을 별도 적용한다.

3-5-4 기본설계 및 실시설계

○ 기본설계 및 실시설계의 산출기준은 엔지니어링사업대가의 기준 중 건설부문 공사비 요율을 적용한다.

3-5-5 실시계획

○ 주택단지개발계획의 표준품 산정내역 중 유사업무를 준용한다.

○ 주택단지개발계획의 산정기준 중 유사업무를 준용한다.

○ 주택단지개발계획의 단위별 변화수정과 보정 중 유사업무를 준용한다.

○ 표준단위 업무분류와 원단위에서 기술업무의 직능별 직접인력 소요작업량은 1.기본계획 업무내용 중 ⑰인·허가 승인도서 작성, 2.성과품작성 업무내용 중 ① 보고서작성 및 편집, ② 관련도서 작성, 3.기술협의 업무내용 중 ③ 위원회심의 지원, ④ 관계기관 협의 중 유사업무를 준용한다.

3-6 주요업무내용

3-6-1 기본계획

구 분	업무내용	내 용
1.기본계획	①현황조사 및 분석	·자연환경조사 ·인문환경조사 ·산업경제조사 ·인접지역과의 연결체계조사 ·기존도시계획 검토 ·관련상위계획 검토
	②개발정비조건 및 계획내용 설정	·개발방향설정 ·계획범위 정립 ·계획의 전제 ·계획인구설정 ·계획지표설정
	③ 구상안 작성	·기본방향설정 ·공간구조구상 ·생활권 구상 ·토지이용구상 ·동선체계구상 ·공원녹지체계구상 ·구상안(대안)비교 및 결정
	④ 인구수용 및 생활권계획	·인구수용계획 ·인구밀도계획 ·생활권계획 ·단위생활권별 인구배분계획

구 분	업무내용	내 용
1.기본계획 (계속)	⑤ 주택계획	·주택호수밀도계획 ·유형별 주택계획 ·평형별 주택계획
	⑥ 공공시설계획	·도시·군계획시설 ·생활편의시설 ·상업업무시설 ·기타 시설
	⑦ 토지이용계획	·기본방향설정 ·토지이용계획(대안)작성 및 비교 분석 ·용도지역계획 ·주택건설용지계획 ·공공시설용지계획 ·가구·획지 분할계획
	⑧ 교통계획	·기본구상설정 ·교통량 수요예측 ·가로망의 기능 및 체계설정 ·가로망 계획안(대안) 작성 및 비교분석 ·간선가로망계획 ·세가로망계획 ·교통시설계획
	⑨ 공급처리시설계획	·상수도계획 ·하수도 및 배수계획 ·통신계획
	⑩ 집단에너지공급계획	·전력 공급계획 ·도시가스 공급계획 ·지역난방공급계획
	⑪ 공원녹지계획	·기본방향설정 ·공원배치계획 ·녹지배치 및 기능배치계획
	⑫ 경관 및 미관계획	·경관관리 대상지역 설정 및 전략 ·조망 및 Sky-Line 지침설정 ·주거단지 환경계획
	⑬ 친환경계획	·기본방향 ·친환경 기준설정 ·Bio-Top 조성계획 ·환경시설계획, 환경영향검토
	⑭ 택지공급계획	·용도별 택지공급계획 ·택지 공급방법결정 ·택지공급추정가격산정
	⑮ 재원조달 및 자금투자계획	·단계별 조성계획 ·재원조달계획 ·자금투자계획
	⑯ 운영관리계획	·연차별 개발계획 ·관리운영계획
	⑰ 인·허가 승인도서 작성	·인·허가 승인도서 작성

3-6-2 실시계획

구 분	업무내용	내 용
2.실시계획	①인 · 허가 승인도서 작성	· 계획평면도 및 설계도 · 공공시설 조서 · 도면 · 인 · 허가 의제 관련 서류
	②보고서 작성 및 편집	· 보고서 작성 및 편집
	③관련도서 작성	· 관계기관 협의서류 등

3-7 표준성과품

3-7-1 기본계획

기본계획 표준성과품

성과구분	표준성과도서			비 고
	구 분	규 격	제출부수	
현황도	·주변관계및현황분석도 ·현황종합분석도 ·기본구상도	1/50,000~1/25,000 1/50,000~1/5,000 1/5,000~1/3,000	1부 〃 〃	위치, 자연환경, 토지이용, 인구, 기정도시계획 등
계획도	·종합기본계획도 ·토지이용계획도 ·교통체계도 ·공급처리시설계획도 ·공원녹지체계도	1/5,000~1/3,000 〃 〃 〃 〃	〃 〃 〃 〃 〃	
보고서	·계획보고서	발주자와 협의결정	발주자와 협의결정	관리운영계획, 사업계획 포함

주 : ①제출부수 및 성과품 종류가 증가할 경우에는 증가배수에 해당하는 작업품과 비용을 가산한다.
②계획보고서 및 기타 관련자료의 규격 및 제출부수는 발주자와의 협의에 의하여 비용을 산정한다.

3-7-2 실시계획

실시계획 표준성과품

성과구분	표준성과도서			비 고
	구 분	규 격	제출부수	
현황도	·위치도	1/50,000~1/25,000	1부	
계획도	·계획평면도 ·실시설계도	발주자와 협의결정	〃 〃	
보고서	·실시계획 도서	〃	발주자와 협의결정	
	·실시계획 보고서	〃	〃	

주 : ①제출부수 및 성과품 종류가 증가할 경우에는 증가배수에 해당하는 작업품과 비용을 가산한다.
②실시계획 보고서 및 기타 관련자료의 규격 및 제출부수는 발주자와의 협의에 의하여 비용을 산정한다.

제4절 산업단지 개발계획

4-1 정 의

○ 산업단지개발계획이라 함은 “산업입지 및 개발에 관한 법률”에서 정한 산업단지를 개발 및 조성하기 위한 국가산업단지, 일반산업단지, 도시첨단산업단지, 농공단지, 준산업단지 등의 엔지니어링활동을 말한다.

○ 이는 포괄적인 계획에 따라 지정·개발되는 일단의 토지에 대한 지목 또는 토지의 형질변경이나 공공시설의 설치변경 등 산업입지에 관련된 일체의 토지개발사업에 관한 제계획(諸計劃)을 말한다.

4-2 자료제공의 전제

○ 산업단지개발계획에 필요한 모든 관련자료는 원칙적으로 발주자가 제공하는 것으로 하되, 발주자가 보유하지 않는 자료는 엔지니어링사업자가 조사·수집한다.

○ 발주자가 제공하지 못하는 자료의 조사에 있어서는 그 규모·내용에 의거하여 별도의 엔지니어링사업대가를 산정하여 엔지니어링사업자가 수행하며, 관련자료의 기밀성과 광범위한 자료가 요구될 경우에는 조사·분석에 필요한 상당기간과 자료수집비용이 전제되어야 한다.

4-3 업무범위와 추진과정

4-3-1 업무범위

○ 산업단지개발계획의 업무범위는 국가산업단지, 일반산업단지, 도시첨단산업단지, 농공단지를 조성하기 위하여 시행하는 산업단지개발사업을 기본계획, 기본설계, 실시설계 등 3단계로 구분하고 이를 엔지니어링활동의 주범위로 한다.

4-3-2 추진과정

○ 타부처(관계기관)와 협의나 전문가 자문 등의 기술협의에 소요되는 기간은 과업수행기간에서 제외하여 그 소요기간만큼 과업수행기간을 연장하여야 한다.

산업단지 개발계획 업무추진과정

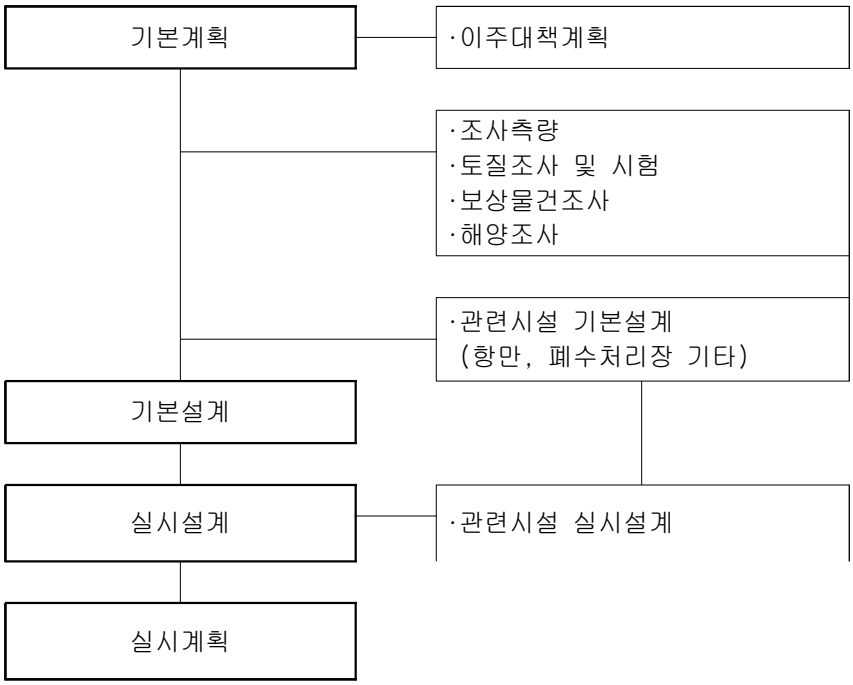

4-4 품 산정의 원단위 산정과 기준

4-4-1 표준품 산정내역

○ 표준품 산정의 기준이 되는 비목은 제1장 총칙에서 제시한 비목을 중심으로 하였으며, 이는 산업단지개발계획에 필요한 사항만을 대상으로 한다.

○ 표준품 산정의 기본이 되는 직접인건비 품의 작업항목별 보할은 항목별 업무의 난이도를 감안하여 설정토록 한다.

종 별		내 용		단 위	비 고
직접비	직접인건비	1.기본계획	①현황조사 및 분석 ②개발정비조건 및 계획내용 설정 ③유치업종 검토 ④유치업종별 원단위 및 규격결정 ⑤인구유발 효과 및 수용계획 ⑥지역경제 파급효과 ⑦구상안 작성 ⑧업종별배분계획 ⑨토지이용계획 ⑩동선계획 ⑪공급처리시설계획 ⑫공원녹지계획 ⑬환경관리계획 ⑭용지공급계획 ⑮재원조달 및 자금투자계획 ⑯운영관리계획 ⑰인·허가 승인도서 작성	인·일 〃 〃 〃 〃 〃 〃 〃 〃 〃 〃 〃 〃 〃 〃 〃 〃	
		2.성과품작성	①보고서작성 및 편집 ②관련도서 작성	〃 〃	
		3.기술협의	①공청회/주민설명회 ②주민간담회/시민계획단 ③위원회심의 지원 ④관계기관 협의	〃 〃 〃 〃	
		4.조사측량	측량품 별도적용		
		5.토질조사 및 시험	토질조사 및 시험 품 별도적용		
		6.기본설계	엔지니어링사업대가의 기준 중 건설부문 공사비 요율을 적용		
		7.실시설계	엔지니어링사업대가의 기준 중 건설부문 공사비 요율을 적용		
		8.실시계획	기본계획, 성과품작성, 기술협의 업무내용중 실시계획 관련 항목만 적용		
	직접경비	여비, 인쇄비, 조감도, 회의준비비, 현장운영비 등		식	제1장 총칙참조
간접비	제경비	(직접인건비)×120%		〃	〃
	기술료	(직접인건비+제경비) ×30%		〃	〃

주 : 산업단지개발계획에 관련되는 엔지니어링활동업무인 이주대책계획, 타당성조사, 조사측량, 보상물건조사(유형보상), 토질조사 및 시험과 폐수처리장, 폐기물처리장, 특수공해방지시설 등과 같은 관련시설의 기본설계와 실시설계, 임해산업단지의 해양조사 및 항만시설의 기본설계 및 실시설계, 단지분양, 각종영향성검토 및 각종영향평가 등과 같은 엔지니어링활동은 별도 전문분야 엔지니어링활동업무로 계상하도록 한다.

4-4-2 산정기준

1. 계획·기준면적의 설정

○ 기준면적은 50만㎡로 하였으며, 직능별 직접인력 소요원단위는 기 작성된 산업단지개발계획 등의 투입기술자 비율을 감안하여 설정하였다.

○ 계획면적은 산업단지개발계획의 지정 또는 과업면적을 원칙으로 한다.

2. 표준품의 산정방법

○ 표준품의 적용에 있어 기준면적과 계획면적의 차이에 따른 품 산정은 아래의 수정식에 따라 기준면적의 소요작업량을 수정하여 산정한다.

○ 소요작업량 = 기준면적소요작업량× 면적보정계수(α)× 과업밀도보정계수(β)

3. 계획안의 수정과 과업중지 등에 따른 산정방법

○ 계획안이 작성되고 공청회, 주민공람, 의회보고 등 기술협의과정을 거쳐 계획안이 확정된 후 발주자의 사정에 의하여 계획안이 일부변경·재작업이 수행되는 경우에는 그 변경·재작업의 정도에 따라 엔지니어링사업대가의 50～100% 수준에서 비용을 추가 지급하여야 한다.

○ 과업수행 중 발주자의 사정에 따른 과업 중단으로 인해 정부 회계연도가 경과되어 현저한 비용의 차이가 발생하였을 경우에는 엔지니어링사업대가를 당해 신년도의 노임단가를 기준으로 재산정하여야 한다.

4-4-3 단위별 변화수정과 보정

1. 작업량 보정계수 산정

1) 면적의 대소에 대한 작업량 보정계수 산정

○ 계획면적이 기준면적을 초과하거나 못 미치는 경우의 직접인력 소요작업량의 산정을 위한 면적보정계수(α)는 다음의 식에 의해 산정한다.

$$\alpha = \left(\frac{\text{계획면적}}{\text{기준면적}}\right)^{0.6} = \left(\frac{A}{50}\right)^{0.6}$$

α = 보정계수
A = 계획면적(만㎡)

계획단위 면적별 보정계수

면 적 (만㎡)	보정계수 (α)	면 적 (만㎡)	보정계수 (α)
3	0.185	70	1.224
10	0.381	100	1.516
20	0.577	150	1.933
30	0.736	200	2.297
50	1.000	300	2.930

주 : 계획면적이 3만㎡미만인 경우에는 계획면적 3만㎡를 기준으로 하여 산정한다.

2) 과업밀도에 대한 작업량 보정계수 산정

○ 지형의 복잡성, 계획건축물의 밀도정도, 과업축척의 대소, 산업단지 등의 재생에 의한 표준품의 조정은 다음과 같다.

계획단위 밀도별 보정계수

구 분	과업조건의 정도	보정계수(β)
기본계획	대상조건이 복잡한 경우	1.0 ~ 1.25
	구상안 대안작성의 수량	0.8 ~ 1.5
산업단지 재생계획 및 재생시행계획의 경우		1.0 ~ 1.4

2. 직접인건비 소요 작업량 산정

○ 계획면적의 대소에 따른 직접인력 소요작업량의 산정방법은 아래와 같이 기준면적의 직능별 직접인력 소요작업량에 계획단위 보정계수(α, β)을 곱하여 산출한다.

구 분	기준면적 (만㎡)	총작업량 (인·일)					
		기술사	특 급	고 급	중 급	초 급	보조원
산업단지 기본계획	50	12.9αβ	21.6αβ	78.9αβ	79.5αβ	177.7αβ	209.1αβ

4-5 표준단위 업무분류와 원단위

4-5-1 기본계획

기술업무의 직능별 직접인력 소요작업량(면적 50만㎡ 기준)

(단위 : 인·일/표준단위)

구 분	업무내용	표준단위	소요인력						비고
			기술사	특급	고급	중급	초급	보조원	
1.기본계획	①현황조사 및 분석	50만㎡	0.7	2.6	4.7	6.6	13.5	13.5	
	②개발정비조건 및 계획내용 설정	50만㎡	0.9	2.4	4.6	6.6	6.6	9.9	
	③유치업종 검토	50만㎡	0.6	0.8	2.7	2.7	6.7	6.8	
	④유치업종별 원단위 및 규격결정	50만㎡	0.6	0.7	2.7	2.7	10.2	10.1	
	⑤인구유발 효과 및 수용계획	50만㎡	0.6	0.8	2.6	2.6	6.7	6.7	
	⑥지역경제 파급효과	50만㎡	0.5	0.9	4.0	3.9	6.7	10.0	
	⑦구상안 작성	50만㎡	1.3	2.0	4.6	0.0	13.2	13.2	
	⑧업종별배분계획	50만㎡	0.7	0.7	4.1	4.1	6.7	10.1	
	⑨토지이용계획	50만㎡	1.3	1.3	7.5	8.1	27.0	27.0	
	⑩동선계획	50만㎡	0.8	0.5	4.0	4.0	13.2	16.5	
	⑪공급처리시설계획	50만㎡	1.0	1.6	6.7	6.7	13.5	13.5	
	⑫공원녹지계획	50만㎡	0.5	0.8	4.0	4.0	6.6	9.9	
	⑬환경관리계획	50만㎡	0.5	0.9	4.1	4.0	6.8	10.2	
	⑭용지공급계획	50만㎡	0.5	0.9	4.0	3.8	6.6	9.9	
	⑮재원조달 및 자금투자계획	50만㎡	0.5	0.9	3.9	3.7	7.0	6.0	
	⑯운영관리계획	50만㎡	0.4	0.9	2.6	4.0	6.6	9.9	
	⑰인·허가 승인도서 작성	50만㎡	0.9	0.4	4.0	4.0	6.6	9.9	
	소 계		12.3	19.1	70.8	71.5	164.2	193.1	
2.성과품작성	①보고서작성 및 편집	50만㎡	0.3	1.3	4.1	4.0	6.9	5.9	
	②관련도서 작성	50만㎡	0.3	1.2	4.0	4.0	6.6	10.1	
	소 계		0.6	2.5	8.1	8.0	13.5	16.0	
계			12.9	21.6	78.9	79.5	177.7	209.1	
3.기술협의	①공청회/주민설명회	1식	2.0	2.0	2.0	4.0	4.0	4.0	주1
	②주민간담회/시민계획단	1식	2.0	2.0	2.0	4.0	4.0	4.0	
	③위원회심의 지원	1식	2.0	2.0	2.0	4.0	4.0	4.0	
	④관계기관 협의	1식	2.0	2.0	2.0	4.0	4.0	4.0	
	소 계		8.0	8.0	8.0	16.0	16.0	16.0	

주 : ①기술협의는 2회 이내 기준이며, 횟수가 늘어날 경우 증가배수에 해당하는 작업품과 비용을 가산한다. (필요항목 선택적 적용)

②보상물건조사업무를 포함 시행할 경우 직접인건비 산정방법은 제2절 환지방식개발계획의 보상계획(유형보상) 2-5-5를 준용한다.

③각종영향성검토 및 각종영향평가업무는 별도의 엔지니어링활동업무로 계상한다.

4-5-2 조사측량

○ 측량품을 별도 적용한다.

4-5-3 토질조사 및 시험

○ 토질조사 및 시험품을 별도 적용한다.

4-5-4 기본설계 및 실시설계

○ 기본설계 및 실시설계의 산출기준은 엔지니어링사업대가의 기준 중 건설부문 공사비 요율을 적용한다.

4-5-5 실시계획

○ 산업단지개발계획의 표준품 산정내역 중 유사업무를 준용한다.

○ 산업단지개발계획의 산정기준 중 유사업무를 준용한다.

○ 산업단지개발계획의 단위별 변화수정과 보정 중 유사업무를 준용한다.

○ 표준단위 업무분류와 원단위에서 기술업무의 직능별 직접인력 소요작업량은 1.기본계획 업무내용 중 ⑰인·허가 승인도서 작성, 2.성과품작성 업무내용 중 ① 보고서작성 및 편집, ② 관련도서 작성, 3.기술협의 업무내용 중 ③ 위원회심의 지원, ④ 관계기관 협의 중 유사업무를 준용한다.

4-6 주요업무내용

4-6-1 기본계획

구 분	업무내용	내 용
기본계획	①현황조사 및 분석	·자연환경조사 ·인문환경조사 ·산업경제조사 ·상위계획검토 ·기존계획 검토 ·인접지역과의 연계성검토
	②개발정비조건 및 내용 설정	·개발정비방향설정 ·계획범위 정립 ·계획의 전제 ·계획내용설정
	③유치업종검토	·전국 산업발전계획 검토 ·전국 산업입지 수요추정 검토 ·지역별 산업입지 검토 ·인접지 산업 관련관계 검토 ·적정유치 업종 검토
	④유치업종별 원단위 및 규모 결정	·업종별 원단위의 비교 분석 ·업종별 적정원단위 설정 ·업종별 적정규모 조사 ·업종별 유치업체규모 설정
	⑤인구유발 효과 및 수용 계획	·인구유발효과 ·유발인구 수용계획
	⑥지역경제 파급효과	·직접파급효과,간접파급효과
	⑦구상안 작성	·지역관련성 분석 ·공간구조 구상 ·토지이용 구상 ·동선체계 구상 ·녹지체계 구상 ·구상안(대안)비교 및 결정

구 분	업무내용	내 용
기본계획 (계속)	⑧업종별 배분계획	·배분기준작성 ·업종별 배분계획 ·지원시설배치계획
	⑨토지이용계획	·산업단지 배치기능 설정 ·공간구성체계 설정 ·토지이용구상안(대안) 작성 ·용도지역 설정 ·토지이용종합계획 작성
	⑩동선계획	·기본방향의 설정 ·교통수요 추정 ·가로망의 기능 및 체계설정 ·가로망 구상안(대안) 작성 ·가로망계획 확정 ·교통시설계획
	⑪공급처리시설계획	·공업용수·생활용수계획 ·하수도 및 배수계획 ·폐수처리 기본방향 제시 ·통신계획 ·전력공급계획 ·도시가스공급계획, 지역난방공급계획
	⑫공원녹지계획	·공원녹지체계 설정 ·공원녹지배치계획
	⑬환경관리계획	·공해방지계획 ·방재계획 ·환경보전계획 ·공장폐기물처리계획
	⑭용지공급계획	·용도별 부지공급계획 ·용도별 공급방법결정 ·용도별 공급추진가격산정
	⑮재원조달 및 자금투자계획	·재원조달계획 ·자금투자계획
	⑯운영관리계획	·연차별 개발계획 ·운영관리계획
	⑰인·허가 승인도서 작성	·인·허가 승인도서 작성

4-6-2 실시계획

구 분	업무내용	내 용
실시계획	①인 · 허가 승인도서 작성	·계획평면도 및 설계도 ·공공시설 조서 · 도면 ·인 · 허가 의제 관련 서류
	②보고서 작성 및 편집	·보고서 작성 및 편집
	③관련도서 작성	·관계기관 협의서류 등

4-7 표준성과품

4-7-1 기본계획

성과구분	표준성과도서			비 고
	구 분	규 격	제출부수	
현황도	·주변관계 및 현황분석도 ·현황종합분석도 ·기본구상도	1/50,000~1/25,000 1/50,000~1/5,000 1/5,000~1/3,000	1부 〃 〃	위치, 환경, 토지이용, 기존계획, 교통 주요시설, 공해 등
계획도	·종합기본계획도 ·토지이용계획도 ·업종별배분계획도 ·교통체계도 ·공급처리시설계획	1/5,000~1/3,000 〃 〃 〃 〃	〃 〃 〃 〃 〃	
보고서	·계획보고서	발주자와 협의결정	발주자와 협의결정	관리운영계획 사업계획 포함

주 : ①제출부수 및 성과품 종류가 증가할 경우에는 증가배수에 해당하는 작업품과 비용을 가산한다.
②계획보고서, 기타 관련자료의 규격 및 제출부수는 발주자와의 협의에 의하여 비용을 산정하여 계상한다.

4-7-2 실시계획

성과구분	표준성과도서			비 고
	구 분	규 격	제출부수	
현황도	·위치도	1/50,000~1/25,000	1부	
계획도	·계획평면도 ·실시설계도	발주자와 협의결정	〃 〃	
보고서	·실시계획 도서	〃	발주자와 협의결정	
	·실시계획 보고서	〃	〃	

주 : ①제출부수 및 성과품 종류가 증가할 경우에는 증가배수에 해당하는 작업품과 비용을 가산한다.
②실시계획보고서 및 기타 관련자료의 규격 및 제출부수는 발주자와의 협의에 의하여 비용을 산정한다.

제5절 「캠퍼스」계획

5-1 정 의

○ 「캠퍼스」계획이라 함은 계획적인 캠퍼스(초등학교, 중·고등학교, 대학교)입지를 전제로 「캠퍼스」의 기능 및 미관의 증진을 위한 장기적 종합적인 사업으로서 「캠퍼스」시설 및 토지이용계획 등을 구체화하고 건축물의 위치, 규격, 용도, 형태와 공간의 활용 등 「캠퍼스」의 물적환경개선을 위한 총체적인 계획을 말한다.

5-2 자료제공의 전제

○ 「캠퍼스」계획에 필요한 모든 관련자료는 원칙적으로 발주자가 제공하는 것으로 하되, 발주자가 보유하지 않는 자료는 엔지니어링사업자가 조사·수집한다.

○ 발주자가 제공하지 못하는 자료의 조사에 있어서는 그 규모·내용에 의거하여 별도의 엔지니어링사업대가를 산정하여 엔지니어링사업자가가 수행하며, 관련자료의 기밀성과 광범위한 자료가 요구될 경우에는 조사·분석에 필요한 상당기간과 자료수집비용이 전제되어야 한다.

5-3 업무범위와 추진과정

5-3-1 업무범위

○ 「캠퍼스」계획은 기본계획, 기본설계, 실시설계 등을 주요업무범위로 한다.

5-3-2 추진과정

○ 타부처(관계기관)와 협의나 전문가 자문 등에 소요되는 기간은 과업수행기간에서 제외하여 그 소요기간만큼 과업수행기간을 연장하여야 한다.

「캠퍼스」계획 업무추진과정

5-4 품 산정의 원단위 산정과 기준

5-4-1 표준품 산정내역

○ 주택단지개발계획의 표준품 산정내역 중 유사업무를 준용한다.

5-4-2 산정기준

○ 주택단지개발계획의 산정기준 중 유사업무 품을 준용한다.

5-4-3 단위별 변화수정과 보정

○ 주택단지개발계획의 단위별 변화수정과 보정 중 유사업무를 준용한다.

5-5 표준단위 업무분류와 원단위

○ 주택단지개발계획의 표준단위 업무분류와 원단위 중 유사업무를 준용한다.

5-6 주요업무내용

5-6-1 기본계획

구 분	항 목	내 용
1.개발여건분석	①자연환경조사	·수계, 토양 및 지질, 지형, 지세 등의 조사 ·기온, 강수량, 풍향, 풍속, 천기일수 등의 조사 ·기타 식생 등 경관조사
	②인문환경조사	·토지이용현황, 교통시설, 기반시설 조사 ·역사성 등 지역성격 조사 ·관련법규 및 계획검토
	③종합분석	·제반현황의 종합적 분석 ·개발잠재력 및 문제점 분석
2.기본구상	①개발방향설정	·개발잠재력에 의한 개발방향설정
	②계획지표설정	·인구지표설정 ·이용인구의 구성, 규모설정
	③토지이용체계구상	·공간구성체계설정 ·토지이용구상안 작성
	④동선체계구상	·이용자의 이용체계구상 ·토지이용에 따른 기능별 동선구상
	⑤유치시설 종류 및 규모설정	·적정수용능력판단 ·시설 종류 및 규모설정
3.기본계획 (부문별)	①토지이용계획	·공간구성체계설정 ·토지이용종합계획수립
	②교통동선계획	·교통량수요추정 ·가로망체계설정 ·간선가로망계획 ·세가로망계획
	③시설물배치계획	·주요시설물(건축·조경)의 배치계획
	④식재계획	·식재계획
	⑤공급처리시설계획	·상하수도, 전기통신 부문에 대한 용량추정 및 공급처리방안
	⑥환경보전계획	·환경보전 및 관리계획 ·재해방지계획
4.사업계획	①사업투자계획	·개략공사비 산정 ·공종별, 재원별 투자계획 ·단계별, 년차별 투자계획
	②관리운영계획	·환경보전방안제시 ·관리체계 및 대책제시 ·운영방안제시

주 : 본 사업에 관련되는 부수적인 업무인 조사, 측량, 토질조사 및 시험, 각종영향성검토 및 각종영향평가업무 등은 별도 엔지니어링활동업무로 간주한다.

5-6-2 실시계획

구 분	항 목	내 용
실시계획	①인 · 허가 승인도서 작성	·계획평면도 및 설계도 ·공공시설 조서 · 도면 ·인 · 허가 의제 관련 서류
	②보고서 작성 및 편집	·보고서 작성 및 편집
	③관련도서 작성	·관계기관 협의서류 등

5-7 표준성과품

5-7-1 기본계획

성과구분	표준성과도서			비 고
	구 분	규 격	제출부수	
현황도	·위 치 도 ·현황종합분석도	1/50,000~1/25,000 1/50,000~1/5,000	1부 〃	
계획도	·종합기본계획도 ·토지이용계획도 ·교통동선계획도 ·시설물배치계획도 ·식재계획도 ·공급처리시설계획도	1/5,000~1/3,000 〃 〃 〃 〃 〃	〃 〃 〃 〃 〃 〃	조경, 건축
보고서	·계획보고서	발주자와 협의결정	발주자와 협의결정	관리운영계획 사업계획 포함

주 : ①제출부수 및 성과품 종류가 증가할 경우에는 증가배수에 해당하는 작업품과 비용을 가산한다.
②계획보고서, 기타 관련자료의 규격 및 제출부수는 발주자와의 협의에 의하여 비용을 산정하여 계상한다.

5-7-2 실시계획

성과구분	표준성과도서			비 고
	구 분	규 격	제출부수	
현황도	·위치도	1/50,000~1/25,000	1부	
계획도	·계획평면도 ·실시설계도	발주자와 협의결정	〃 〃	
보고서	·실시계획 도서	〃	발주자와 협의결정	
	·실시계획 보고서	〃	〃	

주 : ①제출부수 및 성과품 종류가 증가할 경우에는 증가배수에 해당하는 작업품과 비용을 가산한다.
②실시계획 보고서 및 기타 관련자료의 규격 및 제출부수는 발주자와의 협의에 의하여 비용을 산정한다.

제6절 유통(물류)단지 개발계획

6-1 정 의

○ 유통(물류)단지 개발계획이라 함은 도시내외의 특정지역을 대상으로, 계획적인 유통시설의 입지를 전제로 하여 유통시설 및 그 시설을 효율적으로 지원하기 위한 지원시설과 이에 부수되는 시설 등의 용지를 개발공급하는 등 그 지역내에서 일어나는 개발행위에 대하여 유통산업 육성에 따른 공법상의 기준에 적합하도록 유도 규제하기 위한 지목변경이나 토지형질변경 등 토지개발사업에 관한 계획을 주대상으로 한다.

6-2 자료제공의 전제

○ 유통(물류)단지 개발계획에 필요한 모든 관련자료는 원칙적으로 발주자가 제공하는 것으로 하되, 발주자가 보유하지 않는 자료는 엔지니어링사업자가 조사·수집한다.

○ 발주자가 제공하지 못하는 자료의 조사에 있어서는 그 규모·내용에 의거하여 별도의 엔지니어링사업대가를 산정하여 엔지니어링사업자가 수행하며, 관련자료의 기밀성과 광범위한 자료가 요구될 경우에는 조사·분석에 필요한 상당기간과 자료수집비용이 전제되어야한다.

6-3 업무범위와 추진과정

6-3-1 업무범위

○ 유통(물류)단지 개발계획의 업무범위는 유통단지 개발타당성 분석 결과로 지정된 유통단지에 공히 적용할 수 있는 기본계획, 기본설계, 실시설계 등 3단계로 구분하고 이를 엔지니어링활동의 주범위로 한다.

6-3-2 추진과정

○ 타부처(관계기관)와 협의나 전문가 자문 등에 소요되는 기간은 과업수행기간에서 제외하여 그 소요기간만큼 과업수행기간을 연장하여야 한다.

유통(물류)단지 개발계획 업무추진과정

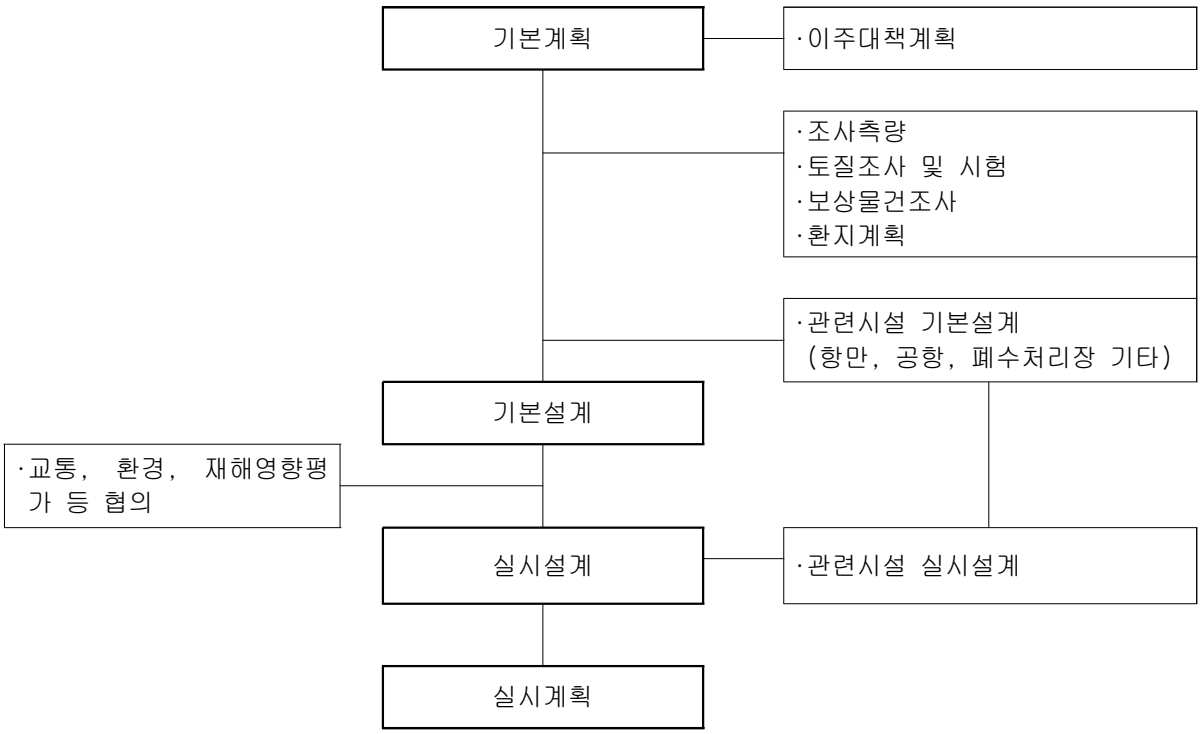

6-4 품 산정의 원단위 산정과 기준

6-4-1 표준품 산정내역

○ 표준품 산정의 기준이 되는 비목은 제1장 총칙에서 제시한 비목을 중심으로 하였으며, 이는 유통(물류)단지 개발계획수립에 필요한 사항만을 대상으로 한다.

○ 표준품 산정의 기본이 되는 직접인건비 품의 작업항목별 보할은 기존의 경험적 내용 및 항목별 업무의 난이도를 감안하여 설정토록 한다.

종 별		내 용		단 위	비 고
직접비	직접인건비	1.기본계획	①기초조사 분석 ②개발정비조건 및 내용 설정 ③유치시설 검토 ④유치시설별 원단위 및 규모결정 ⑤구상안 작성 ⑥유통단지망(Network)구성 ⑦토지이용계획 ⑧동선계획 ⑨유치시설배치계획 ⑩건축계획 ⑪공급처리시설계획 ⑫환경관리계획 ⑬운영관리계획 ⑭인·허가승인도서 작성	인·일 〃 〃 〃 〃 〃 〃 〃 〃 〃 〃 〃 〃 〃	
		2.성과품작성	①보고서작성 및 편집 ②관련도서 작성	〃 〃	
		3.기술협의	①공청회/주민설명회 ②주민간담회/시민계획단 ③위원회심의 지원 ④관계기관 협의	〃 〃 〃 〃	
		4.조사측량	측량품 별도적용		
		5.토질조사 및 시험	토질조사 및 시험품 별도적용		
		6.환지계획	환지방식사업품 별도적용		
		7.보상물건조사	환지방식사업품 별도적용		(유형보상)
		8.기본설계	엔지니어링사업대가의 기준 중 건설부문공사비 요율을 적용		
		9.실시설계	엔지니어링사업대가의 기준 중 건설부문공사비 요율을 적용	식	제1장 총칙참조
		10.실시계획	기본계획, 성과품작성, 기술협의 업무내용중 실시계획 관련 항목만 적용		
	직접경비	여비, 인쇄비, 조감도, 회의준비비, 현장운영비 등		〃	〃
간접비	제경비	(직접인건비)×120%		〃	〃
	기술료	(직접인건비+제경비) ×30%		〃	〃

주 : 유통단지 개발계획에 관련되는 엔지니어링활동업무인 이주대책계획, 타당성조사, 조사측량, 보상물건조사(유형보상), 환지계획, 토질조사 및 시험과 오·폐수처리장, 특수공해방지시설 등과 같은 관련시설의 기본·실시설계, 공항시설의 기본·실시설계, 항만시설관련 해양조사, 기본·실시설계, 각종영향성검토 및 각종영향평가업무 등과 같은 엔지니어링활동은 별도의 엔지니어링활동업무 계상한다.

6-4-2 산정기준

1. 계획·기준면적의 설정

○ 기준면적은 20만㎡로 하였으며, 직능별 직접인력 소요작업량은 기 작성된 투입기술자 비율을 감안하여 설정하였다.

○ 계획면적은 유통(물류)단지 개발계획의 지정 또는 과업면적을 원칙으로 한다.

2. 표준품의 산정방법

○ 표준품의 적용에 있어 기준면적과 계획면적의 차이에 따른 품 산정은 아래의 수정식에 따라 기준면적의 소요작업량을 수정하여 산정한다.

○ 소요작업량 = 기준면적소요작업량× 면적보정계수(α)× 과업밀도보정계수(β)

3. 계획안의 수정과 과업중지에 따른 재산정방법

○ 계획안이 작성되고 공청회, 주민공람, 의회보고 등 기술협의과정을 거쳐 계획안이 확정된 후 발주자의 사정에 의하여 계획안이 일부변경·재작업이 수행되는 경우에는 그 변경·재작업의 정도에 따라 엔지니어링사업대가의 50～100% 수준에서 비용을 추가 지급하여야 한다.

○ 과업수행 중 발주자의 사정에 따른 과업 중단으로 인해 정부 회계연도가 경과되어 현저한 비용의 차이가 발생하였을 경우에는 엔지니어링사업대가를 당해 신년도의 노임단가를 기준으로 재산정하여야 한다.

6-4-3 단위별 변화수정과 보정

1. 작업량 보정계수 산정

1) 면적의 대소에 대한 작업량 보정계수 산정

○ 유통(물류)단지계획면적이 기준면적을 초과하거나 이에 못 미치는 경우의 직접인력 소요작업량의 산정을 위한 각 작업내용별 면적보정계수(α)는 다음과 같이 산정한다.

$$\alpha = \left(\frac{\text{계획면적}}{\text{기준면적}}\right)^{0.5} = \left(\frac{A}{20}\right)^{0.5}$$

α = 보정계수
A = 계획면적(만㎡)

계획단위 면적별 보정계수

면 적 (만㎡)	보정계수 (α)	면 적 (만㎡)	보정계수 (α)
3	0.387	50	1.581
5	0.500	70	1.871
10	0.707	100	2.236
20	1.000	200	3.162
30	1.225	300	3.873

주 : 계획면적이 3만㎡미만인 경우에는 계획면적 3만㎡를 기준으로 하여 산정한다

2) 지구밀도의 변화에 따른 수정

○ 복합물류단지, 대규모 쇼핑센터 등과 같이 건축밀도가 높은 특수유통단지는 계획내용의 특성에 따라 아래의 밀도변화에 따른 보정계수(β)를 적용한다.

구 분	보정계수(β)
복합물류단지 또는 쇼핑센터 등 건축밀도가 높은 유통단지	1.3

2. 직접인건비 소요 작업량 산정

○ 계획면적의 대소, 건축밀도 등에 따른 직접인력 소요작업량의 산정방법은 아래와 같이 기준면적의 직능별 직접인력 소요작업량에 계획단위 보정계수(α, β)을 곱하여 산출한다.

구 분	기준면적 (만㎡)	총작업량 (인·일)					
		기술사	특 급	고 급	중 급	초 급	보조원
유통(물류) 단지계획	20	16.8αβ	25.1αβ	69.6αβ	69.8αβ	160.1αβ	179.3αβ

6-5 표준단위 업무분류와 원단위

6-5-1 기본계획

기술업무의 직능별 직접인력 소요작업량(면적 20만㎡ 기준)

(단위 : 인·일/표준단위)

구 분	업무내용	표준단위	소요인력						비고
			기술사	특 급	고 급	중 급	초 급	보조원	
1.기본계획	①기초조사 분석	20만㎡	0.6	1.8	5.0	5.3	13.9	13.9	
	②개발정비조건 및 내용설정	20만㎡	0.8	1.6	4.0	4.2	6.0	7.7	
	③유치시설 검토	20만㎡	0.7	1.2	2.9	2.6	7.4	7.4	
	④유치시설별 원단위 및 규모결정	20만㎡	0.8	1.1	2.9	2.6	7.5	7.5	
	⑤구상안 작성	20만㎡	1.2	2.8	5.0	6.3	7.3	7.3	
	⑥유통단지망 구성	20만㎡	1.1	1.2	2.9	2.6	7.4	7.4	
	⑦토지이용계획	20만㎡	2.0	2.2	8.1	7.8	19.5	22.3	
	⑧동선계획	20만㎡	1.1	1.3	4.3	3.8	12.6	15.7	
	⑨유치시설배치계획	20만㎡	1.3	2.2	5.6	6.1	10.7	12.0	
	⑩건축계획	20만㎡	1.1	1.3	4.3	4.5	11.3	14.0	
	⑪공급처리시설계획	20만㎡	1.4	2.3	7.3	6.5	14.9	14.5	
	⑫환경관리계획	20만㎡	0.9	1.2	4.3	3.9	7.5	10.9	
	⑬운영관리계획	20만㎡	0.8	1.1	2.9	3.8	7.3	10.8	
	⑭인·허가 승인도서 작성 및 협의	20만㎡	2.0	1.0	2.6	2.4	6.8	7.1	
	소 계		15.8	22.3	62.1	62.4	140.1	158.5	
2.성과품작성	①보고서작성 및 편집	20만㎡	0.6	1.5	5.0	4.6	10.0	7.5	
	②관련도서 작성	20만㎡	0.4	1.3	2.5	2.8	10.0	13.3	
	소 계		1.0	2.8	7.5	7.4	20.0	20.8	
계			16.8	25.1	69.6	69.8	160.1	179.3	
3.기술협의	①공청회/주민설명회	1식	2.0	2.0	2.0	4.0	4.0	4.0	1식
	②주민간담회/시민계획단	1식	2.0	2.0	2.0	4.0	4.0	4.0	
	③위원회심의 지원	1식	2.0	2.0	2.0	4.0	4.0	4.0	
	④관계기관 협의	1식	2.0	2.0	2.0	4.0	4.0	4.0	
	소 계		8.0	8.0	8.0	16.0	16.0	16.0	

주 : ①기술협의는 2회 이내 기준이며, 횟수가 늘어날 경우 증가배수에 해당하는 작업품과 비용을 가산한다. (필요항목 선택적 적용)

②보상물건조사업무 및 환지계획을 포함 시행할 경우 직접인건비 산정방법은 제2절 환지방식개발계획의 보상계획(유형보상)을 준용한다.

③유통단지 개발계획에 관련되는 엔지니어링활동업무인 이주대책계획, 타당성조사, 조사측량, 보상물건조사(유형보상), 환지계획, 토질조사 및 시험과 오·폐수처리장, 특수공해방지시설 등과 같은 관련시설의 기본·실시설계, 공항시설의 기본·실시설계, 항만시설관련 해양조사, 기본·실시설계, 각종영향성검토 및 각종영향평가업무 등은 별도의 엔지니어링활동업무 계상한다.

6-5-2 조사측량

○ 측량품을 별도 적용한다.

6-5-3 토질조사 및 시험

○ 토질조사 및 시험품을 별도 적용한다.

6-5-4 기본설계 및 실시설계

○ 기본설계 및 실시설계에 대한 산출기준은 엔지니어링사업대가의 기준 중 건설부문 공사비요율을 적용한다.

6-5-5 실시계획

○ 유통(물류)단지 개발계획의 표준품 산정내역 중 유사업무를 준용한다.

○ 유통(물류)단지 개발계획의 산정기준 중 유사업무를 준용한다.

○ 유통(물류)단지 개발계획의 단위별 변화수정과 보정 중 유사업무를 준용한다.

○ 표준단위 업무분류와 원단위에서 기술업무의 직능별 직접인력 소요작업량은 1.기본계획 업무내용중 ⑭ 인·허가 승인도서 작성, 2.성과품작성 업무내용중 ① 보고서작성 및 편집, ② 관련도서 작성, 3.기술협의 업무내용 중 , ③ 위원회 심의 지원, ④ 관계기관 협의중 유사업무를 준용한다.

6-6 주요업무내용

6-6-1 기본계획

구 분	업무내용	내 용
기본계획	①기초조사분석	·자연환경조사 ·인문환경조사 ·산업경제조사 ·기존 및 상위계획 검토
	②개발정비조건 및 내용 설정	·개발정비방향설정 ·계획범위 정립 ·계획의 전제 ·계획내용설정
	③유치시설검토	·전국 유통단지 계획 검토 ·권역별 유통단지(시설) 수요추정 검토 ·인접지 유통단지(시설) 관련관계 검토 ·적정유치시설 검토
	④유치시설 원단위 및 규모결정	·유치시설 적정원단위 설정 ·유치시설 적정규모 설정 ·시설별 유치규모 설정
	⑤구상안 작성	·공간구조 구상 ·토지이용계획 구상 ·동선체계 구상
	⑥유통단지망(Network)구성	·네트워크 구축방안 구상 ·네트워크 구축효과 ·물류정보시스템 구축방안 수립

구 분	업무내용	내 용
기본계획 (계속)	⑦토지이용계획	·유치시설 배치기능 설정 ·공간구성체계 설정 ·토지이용 구상안(대안) 작성 ·토지이용종합계획 작성
	⑧동선계획	·교통수요 추정 ·동선체계 설정 ·동선체계구상안(대안) 작성 ·동선체계 확정 ·교통시설 계획
	⑨유치시설 배치계획	·배치기준작성 ·유치시설 배치계획
	⑩건축계획	·건축물 설치기준 작성 ·건축물 배치구상 ·건물구조 구축 및 편의시설계획
	⑪공급처리시설계획	·용수공급계획 ·하수도 및 배수계획 ·폐기물처리계획 ·전력통신계획
	⑫환경관리계획	·공해방지대책 ·환경보전계획
	⑬운영관리계획	·연차별 개발계획 ·개략공사비 산정 ·운영관리계획
	⑭인·허가 승인도서 작성 및 협의	·인·허가 승인도서 작성 및 협의

6-6-2 실시계획

구 분	업무내용	내 용
실시계획	①인 · 허가 승인도서 작성	·계획평면도 및 설계도 ·공공시설 조서 · 도면 ·인 · 허가 의제 관련 서류
	②보고서 작성 및 편집	·보고서 작성 및 편집
	③관련도서 작성	·관계기관 협의서류 등

6-7 표준성과품

6-7-1 기본계획

성과구분	표준성과도서			비 고
	구 분	규 격	제출부수	
현황도	·주변관계 및 현황분석도 ·현황종합분석도	1/50,000~1/25,000 1/50,000~1/5,000	1부 〃	위치, 환경, 토지이용, 기존계획, 교통 주요시설, 공해 등
계획도	·기본구상도 ·종합기본계획도 ·토지이용계획도 ·교통체계도 ·시설물배치계획도 ·공급처리시설계획도	1/5,000~1/3,000 〃 〃 〃 〃 〃	〃 〃 〃 〃 〃 〃	
보고서	·계획보고서	발주자와 협의결정	발주자와 협의결정	관리운영계획 사업계획 포함

주 : ①제출부수 및 성과품 종류가 증가할 경우에는 증가배수에 해당하는 작업품과 비용을 가산한다.
②계획보고서, 기타 관련자료의 규격 및 제출부수는 발주자와의 협의에 의하여 비용을 산정한다.

6-7-2 실시계획

성과구분	표준성과도서			비 고
	구 분	규 격	제출부수	
현황도	·위치도	1/50,000~1/25,000	1부	
계획도	·계획평면도 ·실시설계도	발주자와 협의결정	〃 〃	
보고서	·실시계획 도서	〃	발주자와 협의결정	
	·실시계획 보고서	〃	〃	

주 : ①제출부수 및 성과품 종류가 증가할 경우에는 증가배수에 해당하는 작업품과 비용을 가산한다.
②실시계획 보고서 및 기타 관련자료의 규격 및 제출부수는 발주자와의 협의에 의하여 비용을 산정한다.

제6장 도시재생

제1절 도시재생계획

제2절 재정비촉진계획

제3절 도시 및 주거환경정비계획

제4절 리모델링 기본계획

제1절 도시재생계획

1-1 정 의

○ 도시재생계획이란 인구의 감소, 산업구조의 변화, 도시의 무분별한 확장, 주거환경의 노후화 등으로 쇠퇴하는 도시를 지역역량의 강화, 새로운 기능의 도입・창출 및 지역자원의 활용을 통하여 경제적・사회적・물리적・환경적으로 활성화시키고자 수립하는 계획을 말한다.

1-2 자료제공의 전제

○ 당해 계획의 수립에 필요한 모든 관련자료는 원칙적으로 발주자가 제공하는 것으로 하되, 발주자가 보유하지 않는 자료는 엔지니어링사업자가 조사·수집한다.

○ 발주자가 제공하지 못하는 자료의 조사에 있어서는 그 규모·내용에 의거하여 별도의 엔지니어링사업대가를 산정하여 엔지니어링사업자가 수행하며, 당해 관련자료의 기밀성과 광범위한 자료가 요구될 경우에는 조사·분석에 필요한 상당기간과 자료수집비용이 전제되어야 한다.

1-3 업무범위와 추진과정

1-3-1 업무범위

1. 도시재생전략계획

○ 국가도시재생기본방침을 고려하여 도시 전체 또는 일부 지역, 필요한 경우 둘 이상의 도시에 대하여 도시재생과 관련한 각종 계획, 사업, 프로그램, 유형・무형의 지역자산 등을 조사・발굴하고, 도시재생활성화지역을 지정하는 등 도시재생 추진전략을 수립하기 위한 계획

○ 쇠퇴한 기성시가지 위주로 활력을 증진시키기 위하여 지방자치단체와 주민과 기업 등이 인식을 공유하고 공동의 목표를 세워 이를 달성하기 위한 계획

○ 실행력 있고 지속가능한 도시재생전략계획을 수립하기 위한 각 주체간의 연계·협력·소통할 수 있는 시스템을 계획에 포함

○ 도시재생 관련 지원제도·사업을 소관하는 중앙부처간, 지방자치단체 부서간 협업을 통해 쇠퇴도시지역에 집중적으로 지원하고, 물리적 정비사업 뿐 아니라, 경제·사회·문화 등 다양한 부문사업을 도시공간에 연계·융합하는 계획

2. 도시재생활성화계획

○ 도시재생전략계획에 부합하도록 도시재생활성화지역에 대하여 국가, 지방자치단체, 공공기관 및 지역주민 등이 지역발전과 도시재생을 위하여 추진하는 다양한 도시재생사업을 연계하여 종합적으로 수립하는 실행계획

- 물리적 사업과 사회·경제 프로그램사업을 장소단위의 도시재생사업에서 복합화하는 계획
- 개별적 도시재생사업 간의 공간계획 및 사회·경제 프로그램, 주민조직 등을 연계하는 계획
- 도시재생활성화지역의 재생을 위한 행·재정적인 공공지원 방안을 제시하는 계획

○ 근린재생형 활성화계획: 생활권 단위의 생활환경 개선, 기초생활인프라 확충, 공동체 활성화, 골목경제 살리기 등을 위한 도시재생활성화계획

○ 도시경제기반형 활성화계획: 산업단지, 항만, 공항, 철도, 일반국도, 하천 등 국가의 핵심적인 기능을 담당하는 도시・군계획시설의 정비 및 개발과 연계하여 도시에 새로운 기능을 부여하고 고용기반을 창출하기 위한 도시재생활성화계획

1-3-2 추진과정

○ 타부처(관계기관)와 협의나 전문가 자문 등의 기술협의에 소요되는 기간은 과업수행기간에서 제외하여 그 소요기간 만큼 과업수행기간을 연장하여야 한다.

1. 도시재생전략계획의 수립절차

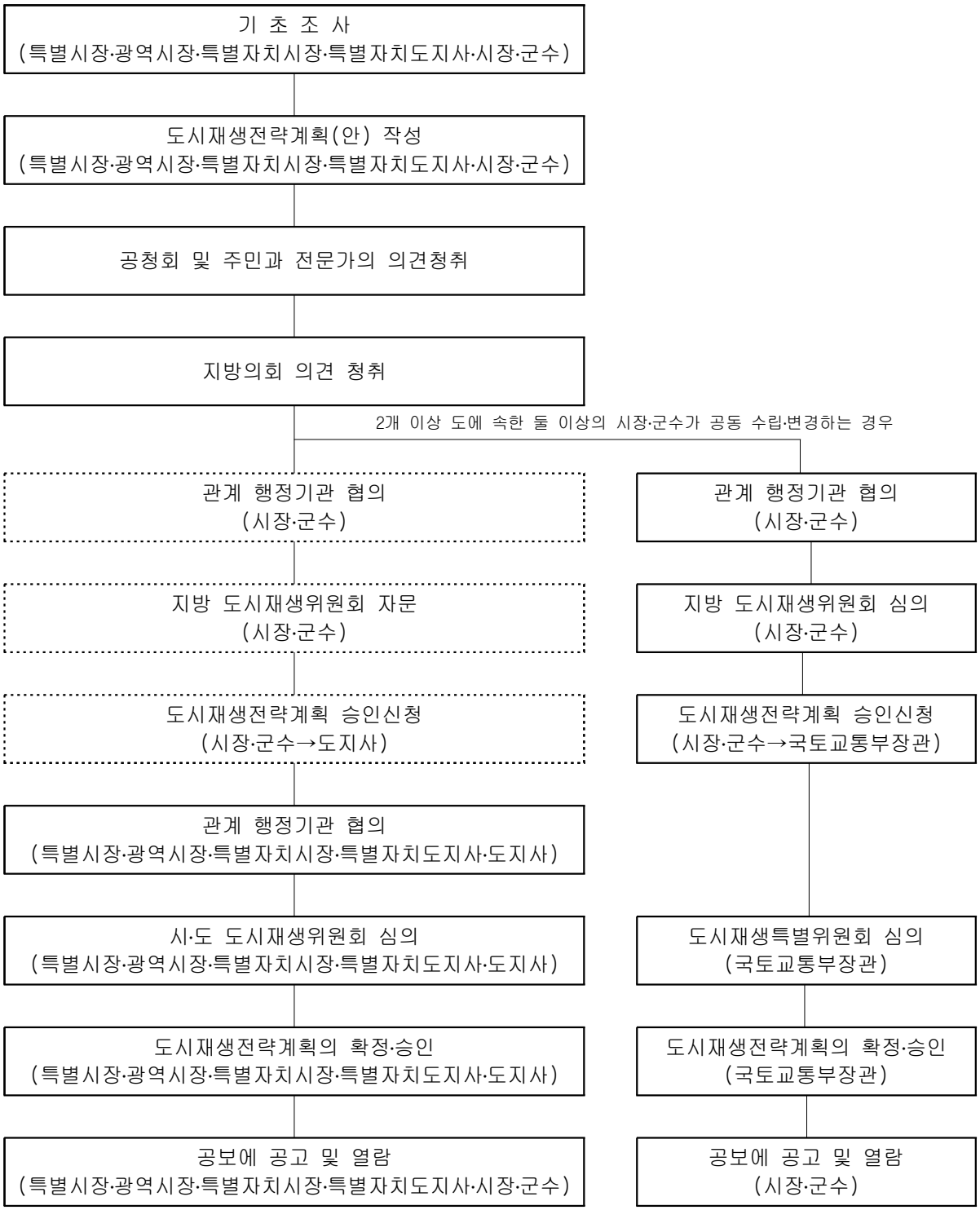

2. 도시재생활성화계획의 수립절차

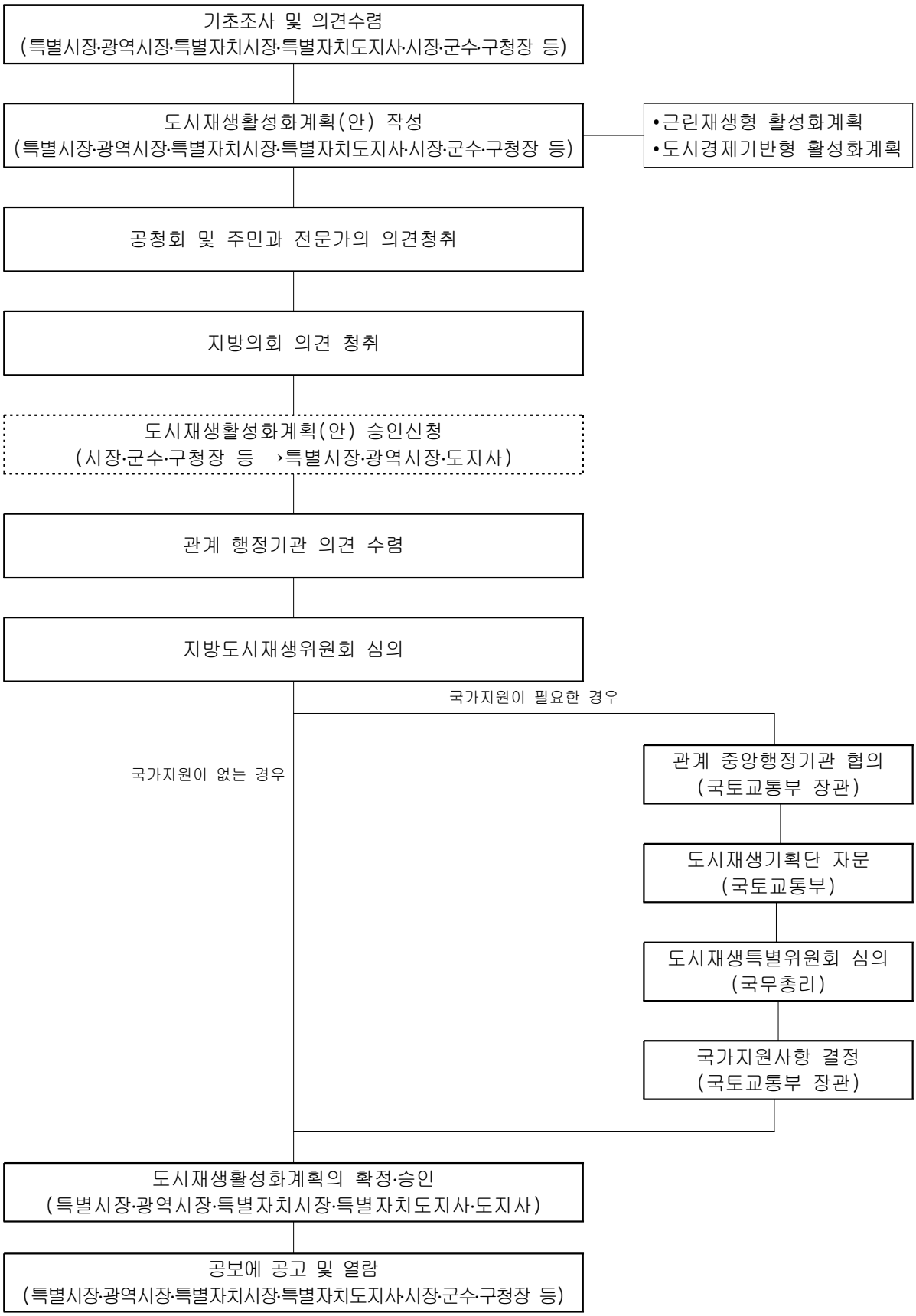

1-4 품 산정의 원단위 산정과 기준

1-4-1 표준품 산정내역

○ 표준품 산정의 기준이 되는 비목은 제1장 총칙에서 제시한 비목을 중심으로 하였으며, 이는 도시재생전략계획에 필요한 사항만을 대상으로 한다.

○ 표준품 산정의 기본이 되는 직접인건비 품의 작업항목별 보할은 업무의 난이도를 감안하여 설정토록 한다.

1. 도시재생전략계획

종 별		내 용	세부항목	단 위	비 고
직접비	직접인건비	1. 기초조사 및 분석	①도시현황 ②지역자산 ③기초생활인프라 현황 ④주거수준 ⑤기타 필요한 사항	인·일 〃 〃 〃 〃	
		2.전략계획	①계획의 목표 및 범위·방안 ②쇠퇴진단 및 여건 분석 ③활성화지역의 지정 · 변경 ④활성화지역별 우선순위 및 지역간 연계방안 ⑤실행 주체 구성 방안 ⑥재원 조달 계획 ⑦지원제도 발굴 ⑧도시재생기반시설의 설치 · 정비 · 개량 계획 ⑨기초생활인프라 계획 ⑩성과관리 방법 및 기준	〃 〃 〃 〃 〃 〃 〃 〃 〃 〃	
		3.성과품작성	①보고서작성 및 편집 ②관련도서작성	〃 〃	
		4.기술협의	①공청회 / 주민설명회 ②주민간담회 / 시민계획단 ③위원회심의 지원 ④관계기관 협의	〃 〃 〃 〃	
	직접경비	여비, 인쇄비, 조감도, 회의준비비, 현장운영비 등		식	제1장 총칙참조
간접비	제경비	(직접인건비)×120%		〃	〃
	기술료	(직접인건비+제경비)×30%		〃	〃

주 : ①기초조사는 도시·군기본계획 수립지침 4-3-1항을 참고로 해당도시의 필요에 따라 조사항목을 가감할 수 있으며 이 경우 제3장 제8절 도시계획 기초조사를 참조하여 엔지니어링사업 대가를 산정한다.

②각종영향성검토 및 각종영향평가업무는 별도의 엔지니어링활동업무로 계상한다.

2. 도시재생활성화계획

종 별		내 용	세부항목	단 위	비 고
직접비	직접인건비	1.기초조사 및 분석	①상위계획 및 관련계획 ②자연환경 ③지역자원 ④인문환경 ⑤도시계획·공간구조·외부공간 ⑥건축물 현황 ⑦산업경제·사회변화·인적자원 ⑧지원 사업	인·일 〃 〃 〃 〃 〃 〃 〃	
		2.활성화계획	①계획의 목표 ②사업의 계획 및 파급효과 ③기반시설의 설치 · 정비 계획 ④재원 조달계획 ⑤예산 집행 계획 ⑥평가 및 점검 계획 ⑦행위제한 지역 계획 ⑧조직의 운영·활성화 방안 사항	〃 〃 〃 〃 〃 〃 〃 〃	
		3.성과품작성	①보고서작성 및 편집 ②관련도서작성	〃 〃	
		4.기술협의	①공청회 / 주민설명회 ②주민간담회 / 시민계획단 ③위원회심의 지원 ④관계기관 협의	〃 〃 〃 〃	
	직접경비	여비, 인쇄비, 조감도, 회의준비비, 현장운영비 등		식	제1장 총칙참조
간접비	제경비	(직접인건비)×120%		〃	〃
	기술료	(직접인건비+제경비)×30%		〃	〃

주 : ①각종영향성검토 및 각종영향평가업무는 별도의 엔지니어링활동업무로 계상한다.
②현황측량비는 측량비품에 의하여 별도 산정한다.

1-4-2 산정기준

1. 계획·기준인구(면적)의 설정

○ 도시재생전략계획의 기준인구는 전국 도시의 인구분포를 분석하여 인구 60만인(전국 시급 도시 평균)으로 하였으며, 직능별 직접인력 소요원단위는 기 작성된 도시・군기본계획 등의 투입기술자 비율을 감안하여 설정하였다.

○ 도시재생전략계획의 계획인구는 계획기준년도의 당해 시・군 인구수(안전행정부 자치단체별 인구수)를 원칙으로 한다.

○ 도시재생활성화계획의 계획면적은 과정별 업무성격에 따라 과업지구면적을 기준으로 산정한다.

○ 사업의 조사·설계 산정의 원단위 책정을 마련하기 위하여 기준인구(면적)을 다음과 같이 설정한다.

구 분	도시재생전략계획	도시재생활성화계획
기준인구(면적)	60만인	10만㎡

2. 표준품의 산정방법

○ 표준품의 적용에 있어 기준인구(면적)과 계획인구(면적)의 차이에 따른 품 산정은 아래의 수정식에 따라 기준인구(면적)의 소요작업량을 수정하여 산정한다.

○ 소요작업량 = 기준인구(면적) 소요작업량 × 인구(면적)보정계수(α, γ) × 계획별 보정계수(β, δ, ζ)

○ 업무에 필요한 자료는 자료제공의 전제에 따라 발주가의 제공이 불가능하여 엔지니어링사업자에게 작성토록 할 경우 그의 내용에 따라 실비로 계상한다.

○ 업무의 수행에 필요한 각종 평가업무(교통, 환경, 재해, 경관)는 제8장 도시평가의 해당 품을 별도 적용하며, 측량·전산처리·시험 등의 경비에 대하여는 실비로 가산한다.

○ 지구단위의 사업시행인가(고시)용 계획 및 건축배치계획을 중심으로 보다 상세한 계획이 요구될 때에는 업무의 범위로 보아 그 소요되는 작업량의 산정은 토목설계의 경우 제5장 3절 주택단지개발계획에 준하며, 건축설계의 경우는 제4장 제1절 지구단위계획의 건축물에 관한 계획의 품을 준용한다.

○ 도시재생전략계획의 기초조사는 도시・군기본계획의 해당품을 적용한다.

3. 계획안의 수정과 과업중지에 따른 품 산정방법

○ 계획안이 작성되고 공청회, 주민공람, 의회보고 등 기술협의과정을 거쳐 계획안이 확정된 후 발주자의 사정에 의하여 계획안이 일부변경·재작업이 수행되는 경우에는 그 변경·재작업의 정도에 따라 엔지니어링사업대가의 50～100% 수준에서 비용을 추가 지급하여야 한다.

○ 과업수행 중 발주자의 사정에 따른 과업 중단으로 인해 정부 회계연도가 경과되어 현저한 비용의 차이가 발생하였을 경우에는 엔지니어링사업대가를 당해 신년도의 노임단가를 기준으로 재산정하여야 한다.

1-4-3 단위별 변화수정과 보정

1. 작업량 보정계수 산정

1) 인구·면적의 대소에 대한 작업량 보정계수 산정

○ 도시의 계획인구(면적)이 기준인구(면적)을 초과하거나 못 미치는 경우의 직접인력 소요작업량의 산정을 위한 보정계수(α)는 다음의 식에 의해 산정한다.

① 도시재생전략계획

$$\alpha = (\frac{\text{계획인구}}{\text{기준인구}})^{0.5} = (\frac{A}{60})^{0.5}$$

α = 보정계수
A = 계획인구(만인)

계획단위 인구별 보정계수

계획인구(만인)	보정계수(α)	계획인구(만인)	보정계수(α)
10	0.408	80	1.155
20	0.577	100	1.291
30	0.707	200	1.826
50	0.913	300	2.236
60	1.000	500	2.887

주 : 계획인구 10만인 미만인 경우에는 계획인구 10만인을 기준으로 하여 산정한다.

② 도시재생활성화계획

$$\gamma = (\frac{\text{계획면적}}{\text{기준면적}})^{0.5} = (\frac{A}{10})^{0.5}$$

γ = 보정계수
A = 계획면적(만㎡)

계획단위 면적별 보정계수

계획면적(만㎡)	보정계수(γ)	면적(만㎡)	보정계수(γ)
1	0.316	30	1.732
3	0.548	50	2.236
5	0.707	70	2.646
10	1.000	80	2.828
20	1.414	100	3.162

주 : 계획면적이 1만㎡미만인 경우에는 계획면적 1만㎡를 기준으로 하여 산정한다.

2) 시가화면적 비율에 따른 작업량 보정계수 산정

○ 도시재생전략계획은 시가화지역(주거, 상업, 공업지역)의 면적에 따라 업무내용과 범위에서 큰 차이를 보이므로, 작업량 보정 계수를 다음과 같이 설정하여 적용한다.

구 분	보정계수(β)
행정구역면적 대비 시가화면적 비율이 7%미만(지방시급 도시 평균)	0.9
행정구역면적 대비 시가화면적 비율이 7% ~ 20%	1.0
행정구역면적 대비 시가화면적 비율이 20%초과(수도권 평균)	1.1

3) 도시재생활성화계획 유형에 대한 작업량 보정계수 산정

○ 도시재생활성화계획은 근린재생형 활성화계획과 도시경제기반형 활성화계획은 계획의 성격상 업무내용과 범위에서 큰 차이를 보이므로, 도시재생활성화계획에 대하여는 작업량 보정 계수를 다음과 같이 설정하여 적용한다.

구 분		보정계수(δ)
근린재생형 활성화계획		1.0
도시경제기반형 활성화계획	도시경제활성화 지원사업, 도시환경개선사업, 공동체 활성화 사업	1.3
	핵심시설사업	1.5

4) 인구밀도의 변화에 따른 수정

ζ = (0.55+0.003P)

ζ = 보정계수
P = 인구밀도(인 / ha)

P	1,000	800	600	500	400	300	250	200	150	100
ζ	3.55	2.95	2.35	2.05	1.75	1.45	1.3	1.15	1	0.85

2. 직접인건비 소요 작업량 산정

○ 계획면적의 대소에 따른 직접인력 소요작업량의 산정방법은 아래와 같이 기준면적의 직능별 직접인력 소요작업량에 계획단위 보정계수(α, β, π, ζ)를 곱하여 산출한다.

구 분	기준인구 ·면적 (만인,만㎡)	총작업량(인·일)					
		기술사	특 급	고 급	중 급	초 급	보조원
전략 계획	60	67.7αβ	108.2αβ	283.8αβ	484.0αβ	615.7αβ	662.5αβ
활성화 계획	10	22.3γδζ	45.3γδζ	108.5γδζ	217.4γδζ	296.3γδζ	311.7γδζ

1-5 표준단위 업무분류와 원단위

1-5-1 도시재생전략계획

기술업무의 직능별 직접인력 소요작업량(인구 60만인 기준)

(단위 : 인·일/표준단위)

구 분	업무내용	표준단위	소요인력						비고
			기술사	특급	고급	중급	초급	보조원	
1.기초조사 및 분석	①도시현황	60만인	11.8	18.9	79.3	119.7	198.8	214.5	
	②지역자산	60만인	1.3	2.1	2.8	7.8	7.8	10.5	
	③기초생활인프라 현황	60만인	1.5	2.3	5.2	10.5	10.2	10.5	
	④주거수준	60만인	1.5	2.3	7.8	10.7	13.1	13.3	
	⑤기타 필요한 사항	60만인	1.3	2.1	5.5	7.8	8.4	7.8	
	소 계		17.4	27.7	100.6	156.5	238.3	256.6	
2.전략계획	①계획의 목표 및 범위·방안	60만인	5.1	8.0	17.5	29.0	22.2	24.2	
	②쇠퇴진단 및 여건 분석	60만인	8.2	12.9	31.9	55.9	59.7	82.3	
	③활성화지역의 지정 · 변경	60만인	13.1	20.9	47.0	80.7	86.4	94.4	
	④우선순위 및 지역간 연계방안	60만인	1.3	2.1	3.9	6.6	9.7	9.2	
	⑤실행 주체 구성 방안	60만인	1.3	2.1	3.9	6.6	9.7	9.2	
	⑥재원 조달 계획	60만인	1.3	2.1	3.9	6.6	9.7	9.2	
	⑦지원제도 발굴	60만인	1.3	2.1	3.9	6.6	9.7	9.2	
	⑧기반시설의 설치 · 정비 · 개량 계획	60만인	6.9	11.1	29.5	60.0	64.2	62.9	
	⑨기초생활인프라 계획	60만인	1.5	2.4	4.9	8.1	11.9	11.5	
	⑩성과관리 방법 및 기준	60만인	1.5	2.5	4.9	8.1	11.9	11.5	
	소 계		41.5	66.2	151.3	268.2	295.1	323.6	
3.성과품 작성	①보고서작성 및 편집	60만인	6.0	9.4	21.2	35.4	35.1	23.3	
	②관련도서작성	60만인	2.8	4.9	10.7	23.9	47.2	59.0	
	소 계		8.8	14.3	31.9	59.3	82.3	82.3	
총 계			67.7	108.2	283.8	484.0	615.7	662.5	
4.기술협의	①공청회/주민설명회	1식	2.0	2.0	2.0	4.0	4.0	4.0	주1
	②주민간담회/시민계획단	1식	2.0	2.0	2.0	4.0	4.0	4.0	
	③위원회심의 지원	1식	2.0	2.0	2.0	4.0	4.0	4.0	
	④관계기관 협의	1식	2.0	2.0	2.0	4.0	4.0	4.0	
	소 계		8.0	8.0	8.0	16.0	16.0	16.0	

주 : ①기술협의는 2회 이내 기준이며, 횟수가 늘어날 경우 증가배수에 해당하는 작업품과 비용을 가산한다. (필요항목 선택적 적용)

②각종영향성검토 및 각종영향평가업무는 별도의 엔지니어링활동업무로 계상한다.

1-5-2 도시재생활성화계획

기술업무의 직능별 직접인력 소요작업량(면적 10만㎡ 기준)

(단위 : 인·일/표준단위)

구 분	업무내용	표준단위	소요인력						비고
			기술사	특급	고급	중급	초급	보조원	
1.기초조사 및 분석	①상위계획 및 관련계획	10만㎡	0.5	1.0	1.3	4.0	5.2	9.0	
	②자연환경	10만㎡	1.1	2.0	5.1	12.7	15.2	17.8	
	③지역자원	10만㎡	0.5	1.0	2.5	6.3	10.3	10.2	
	④인문환경	10만㎡	0.5	1.0	2.5	6.3	10.3	10.2	
	⑤도시계획·공간구조·외부공간	10만㎡	0.5	1.0	1.3	4.0	5.2	9.0	
	⑥건축물 현황	10만㎡	1.0	2.0	5.1	12.7	15.2	17.8	
	⑦산업경제·사회변화·인적자원	10만㎡	1.0	2.4	2.4	7.9	10.0	12.8	
	⑧지원 사업	10만㎡	1.0	2.4	2.4	7.9	10.0	12.8	
	소 계		6.1	12.8	22.6	61.8	81.4	99.6	
2.활성화계획	①계획의 목표	10만㎡	1.5	2.9	7.9	12.7	17.2	16.9	
	②사업의 계획 및 파급효과	10만㎡	2.3	4.6	11.4	22.9	34.5	34.4	
	③기반시설의 설치 · 정비 계획	10만㎡	2.3	4.6	11.4	22.9	34.2	34.4	
	④재원 조달계획	10만㎡	1.4	2.8	7.8	12.6	17.1	16.9	
	⑤예산 집행 계획	10만㎡	1.1	2.3	7.4	14.1	17.1	16.2	
	⑥평가 및 점검 계획	10만㎡	1.4	2.8	7.9	12.6	17.1	16.9	
	⑦행위제한 지역 계획	10만㎡	1.1	2.3	7.4	14.1	17.1	16.2	
	⑧조직의 운영·활성화 방안 사항	10만㎡	1.4	2.8	7.9	12.7	17.2	16.8	
	소 계		12.5	25.1	69.1	124.6	171.5	168.7	
3.성과품작성	①보고서작성 및 편집	10만㎡	2.5	4.9	11.2	18.6	18.7	12.5	
	②관련도서작성	10만㎡	1.2	2.5	5.6	12.4	24.7	30.9	
	소 계		3.7	7.4	16.8	31.0	43.4	43.4	
총 계			22.3	45.3	108.5	217.4	296.3	311.7	
4.기술협의	①공청회/주민설명회	1식	2.0	2.0	2.0	4.0	4.0	4.0	주1
	②주민간담회/시민계획단	1식	2.0	2.0	2.0	4.0	4.0	4.0	
	③위원회심의 지원	1식	2.0	2.0	2.0	4.0	4.0	4.0	
	④관계기관 협의	1식	2.0	2.0	2.0	4.0	4.0	4.0	
	소 계		8.0	8.0	8.0	16.0	16.0	16.0	

주 : ①기술협의는 2회 이내 기준이며, 횟수가 늘어날 경우 증가배수에 해당하는 작업품과 비용을 가산한다. (필요항목 선택적 적용)

②각종영향성검토 및 각종영향평가업무는 별도의 엔지니어링활동업무로 계상한다.

1-6 주요업무내용

1-6-1 도시재생전략계획

구 분	업무내용	내 용
1.기초조사 및 분석	①도시 현황	·상위계획 및 관련계획 ·인구(인구 비중, 인구 이동) ·공간구조(중심지, 시가화지역, 가로) ·토지이용(근린서비스, 재해위험 등) ·건축물(주택수, 노후주택, 주택보급률, 특성건축물, 공가수 등)
	②지역자산	·산업특성(사업체수, 종사자수, 산업분포, 상권 등) ·관련 계획 및 사업현황, 프로그램 ·역사자원·문화자원·인적자원. 관광자원
	③기초생활인프라 현황	·교통시설(공공 주차장),환경기초시설(하수도) ·공간시설(생활권공원, 근린광장) ·유통·공급시설(상수도),방재시설(저류시설) ·공공·문화체육시설(유치원, 초등학교, 공공체육시설, 도서관, 노인의료복지시설 등)
	④주거수준	·평균소득, 실업률 등
	⑤기타 필요한 사항	·도시지역 쇠퇴현황(인구감소, 산업이탈, 건축물 노후화) ·주민조직, 주민(상가)협의체, 마을 기업
2.전략계획	①계획의 목표 및 범위·방안	·도시재생을 위한 목표 및 추진전략 제시 ·지역현황과 특성, 관련계획과의 연계성 확보 ·핵심과제 및 대응전략 도출 ·도시재생 필요지역 도출 ·도시재생 기본구상 수립 ·도시재생 목표달성을 위한 방안
	②쇠퇴진단 및 여건분석	·생활권 단위의 정량적(인구·사회, 산업·경제, 물리·환경 등), 정성적(관련계획, 공간구조, 지역특성 등) 쇠퇴진단 ·여건 분석을 고려한 재생방향 도출
	③활성화지역의 지정 · 변경	·도시재생활성화지역 지정의 세부기준 충족여부 검토 ·도시재생활성화지역의 유형과 기본방향, 경계 설정·변경
	④우선순위 및 지역간 연계방안	·평가항목 설정 및 분석, 우선순위 설정 ·우선순위 및 계획방향, 계획내용 등을 고려한 도시재생활성화지역별 연계방안
	⑤실행주체 구성방안	·전담조직의 조직체계, 업무범위, 조직운영방안 등의 운영계획 수립 ·행정협의체의 구성·운영방안 ·도시재생 지원센터의 설치 및 교육·지원 등의 운영계획 ·다양한 실행 주체의 참여방안
	⑥재원조달계획	·연차별 재원조달방안 및 집행계획, 재정지원 사항, 민간투자유치방안 등 검토 ·개별 도시재생사업에 대한 국비 보조 및 융자와의 중복여부 검토
	⑦지원제도 발굴	·국정과제와의 연계 및 반영을 위한 제시 ·도시재생활성화를 위한 지원조례, 협정 지침 등 마련

구 분	업무내용	내 용
2.전략계획 (계속)	⑧기반시설의 설치 · 정비 개량 계획	·관련계획 및 계획적 도시재생, 계획의 유연성을 고려한 계획 수립 ·기초생활인프라 최저기준 달성계획과의 연계
	⑨기초생활인프라 계획	·기초생활인프라 현황 별도 조사 ·기초생활인프라의 최저기준 달성을 위한 계획 수립
	⑩성과관리 방법 및 기준	·재생목표를 반영할 수 있는 실질적 평가지표(정량적, 정성적) 선정 ·세부지표별 조사주기와 시기, 조사방법 등 제시

1-6-2 도시재생활성화계획

구 분	업무내용	내 용
1.기초조사 및 분석	①상위계획 및 관련계획	·상위 계획 및 관련계획 ·관련 계획 및 사업현황, 프로그램
	②자연환경	·지형, 경사, 하천, 녹지현황 등 ·재해요인 및 현황, 환경오염 현황 등
	③지역자원	·자연자원, 문화·체육시설, 역사자원, 인문자원과 문화재 ·역사적 유물 또는 전통건물·시장, 지역축제·행사 등 문화자원 등
	④인문환경	·인구구조 (성별 ·연령별 구성 , 변화율 등), 인문·사회 분야로 주택수급과 인구 , 주택관련시설, 가구 소득 및 지역안전등 ·생활보호 대상자 및 최저주거 수준미달 가구현황, 기초생활 수급자 현황 , 독거노인 가구비, 노령화 지수, 범죄율 등
	⑤도시계획·공간구조·외부공간	·용도지역·지구, 교통시설, 복지시설, 공공청사, 교육·문화시설, 공간시설, 기타 기반시설(도로, 상·하수도 등 도시재생기반시설 및 공동이용시설) 등 ·도시공간구조, 도시조직 분야로 중심지체계 등 ·가구 및 필지, 건축물 및 필지, 가로와의 관계 등 ·옥외공간 조성현황, 가로공간 이용행태 등
	⑥건축물 현황	·각 지역의 유형별·규모별 주택의 구성 및 변화추이, 노후 ·불량 건축물의 정도, 주택밀도, 주택접도율 등 ·주택의 가격과 소유 및 이용 형태, 공가 및 공실점포, 신규주택비율 등
	⑦산업경제·사회변화·인적자원	·종사자수 및 사업체수(증감률), 실업률, 재정자립도, 지방세 징수액, 공시지가 등 ·성장 및 쇠퇴산업 추이 ·사회적 경향, 인구 및 가구 변화 경향 등 ·주요인물, 대표자, 주민조직, 시민단체, NGO·NPO, 사회적기업, 협동조합, 지역전문가 등 ·봉사단체, 상인회 등
	⑧지원 사업	·중앙부처 및 지방자치단체 부서별 도시재생 관련 지원 사업의 항목 및 개요 등

구 분	업무내용	내 용
2.활성화 계획	①계획의 목표	·도시재생전략계획 및 관련계획, 지역 잠재력, 주민의견 등을 검토 ·기본목표 및 핵심과제, 목표지표, 실천전략 제시 ·기본구상 작성(도시재생방향과 도시재생사업 구상도 포함)
	②사업의 계획 및 파급효과	·도시재생활성화 사업계획 - 사업의 필요성과 방향, 목표, 개요 및 주요내용 등 - 토지이용계획, 기반시설계획, 동선계획, 프로그램계획 등 부문별 계획 - 운영조직 및 주체별 역할 - 추진일정, 재원조달 및 예산집행계획 - 사업효과 및 사후관리방안 등 ·주변지역 연계계획 - 인접 도시재생사업과 주변지역과의 연계에 관한 사항 - 도시재생사업 간 우선순위에 관한 사항 ·핵심시설사업과의 연계계획(도시경제기반형) - 사업의 기본적인 용도 및 배치에 대한 개략적 내용 - 핵심시설사업과의 물리적, 사회·경제프로그램, 추진 주체의 연계계획 - 경제파급효과 등 지역사회 영향분석 ·지표계획 수립 및 파급효과 추정
	③기반시설의 설치 · 정비 계획	·설치·정비 필요성과 사업주체, 사업비 등 제시 ·도시·군계획시설 결정(변경)조서 및 시설별 설치계획 ·준공 후의 운영주체 및 관리방안
	④재원 조달계획	·국비, 지방비, 민간참여개발 등 재원조달 및 확보방안 구상 ·시·군 예산, 제3섹터 방식 및 민간자본 등 조달계획
	⑤예산 집행 계획	·우선순위 선정 ·단계별 추진계획
	⑥평가 및 점검계획	·도시재생전략계획의 평가지표 및 성과관리방안 고려 ·목표지표의 평가를 위한 주체, 기간, 방법 등 제시
	⑦행위제한 지역 계획	·행위제한 지역의 지정·변경 ·행위제한 사유·제한대상행위 및 제한기간, 관리방안
	⑧조직의 운영·활성화 방안 사항	·경제 · 사회 · 문화 · 복지 등 프로그램의 운영이 수반되는 도시재생사업의 운영주체, 운영방안 제시 ·사업구상안 수립을 위한 주민조직 등 참여주체의 역할 및 협업 과정 마련 ·도시재생활성화계획 수립 및 사업시행을 위한 관련주체 간 협력체계 구축 및 운영방안 ·전담조직, 도시재생지원센터 등을 통한 정보제공 및 의견 수렴 등의 지원방안 ·협력조직 구성 및 지원방안 ·주민역량강화프로그램 활용·개발 방안 ·사업계획 및 도시재생기반시설의 설치·정비계획, 재원조달 및 예산집행계획 등을 고려한 도시재생사업간 연계방안

1-7 표준성과품

1-7-1 도시재생전략계획

성과구분	표준성과도서			비 고
	구 분	규 격	제출부수	
계획도	·도시재생전략계획 총괄도 ·도시재생활성화지역 표시도	1/25,000 또는 1/50,000 1/3,000 또는 1/5,000	1부 〃	도시별 적정 축척 사용
보고서	·도시재생전략계획 보고서 ·기초조사 및 계획수립 관련 자료집	발주자와 협의 결정	발주자와 협의결정	

주 : ①제출부수 및 성과품 종류가 증가할 경우에는 증가배수에 해당하는 작업품과 비용을 가산한다.
②계획보고서 및 기타 관련자료의 규격 및 제출부수는 발주자와의 협의에 의하여 비용을 산정한다.

1-7-2 도시재생활성화계획

성과구분	표준성과도서			비 고
	구 분	규 격	제출부수	
현황도	·토지이용 현황도 ·건물 현황도 ·도시시설 현황도	1/3,000 또는 1/500 〃 〃	1부 〃 〃	지역지정시 현황측량이 필요할 경우 발주자와 협의하여 별도 작성제출
계획도	·토지이용 계획도 ·도시재생활성화지역 계획도 ·도시·군계획시설 계획도 ·종합 계획도	1/3,000 또는 1/500 〃 〃 〃	〃 〃 〃 〃	
보고서	·계획 보고서	발주자와 협의결정	발주자와 협의결정	
조감도	·계획구역 조감도	발주자와 협의결정	1식	지역규모에 따라 조정가능

주 : ①제출부수 및 성과품 종류가 증가할 경우에는 증가배수에 해당하는 작업품과 비용을 가산한다.
②계획보고서 및 기타 관련자료의 규격 및 제출부수는 발주자와의 협의에 의하여 비용을 산정한다.

제2절 재정비촉진계획

2-1 정 의

○ 재정비촉진계획은 도시의 낙후된 지역에 대한 주거환경의 개선, 기반시설의 확충 및 도시기능의 회복을 통한 도시의 균형발전과 주민의 삶의 질 향상을 목적으로 광역적으로 계획하고 체계적·효율적으로 사업을 추진하기 위한 토지이용, 기반시설의 설치 등에 관한 계획을 말한다.

2-2 자료제공의 전제

○ 당해 계획의 수립에 필요한 모든 관련자료는 원칙적으로 발주자가 제공하는 것으로 하되, 발주자가 보유하지 않는 자료는 엔지니어링사업자가 조사·수집한다.

○ 발주자가 제공하지 못하는 자료의 조사에 있어서는 그 규모·내용에 의거하여 별도의 엔지니어링사업대가를 산정하여 엔지니어링사업자가 수행하며, 당해 관련자료의 기밀성과 광범위한 자료가 요구될 경우에는 조사·분석에 필요한 상당기간과 자료수집비용이 전제되어야 한다.

2-3 업무범위와 추진과정

2-3-1 업무범위

○ 지구특성에 따라 주거지형, 중심지형, 고밀복합형으로 구분된 재정비촉진지구의 지정업무와 촉진구역별 정비계획, 지침을 정하는 촉진계획수립 업무를 말한다.

가. 주거지형 : 노후·불량 주택과 건축물이 밀집한 지역으로서 주로 주거환경의 개선과 기반시설의 정비가 필요한 지구

나. 중심지형 : 상업지역, 공업지역 등으로서 토지의 효율적 이용과 도심 또는 부도심 등의 도시기능의 회복이 필요한 지구

다. 고밀복합형 : 주요 역세권, 간선도로의 교차지 등 양호한 기반시설을 갖추고 있어 대중교통 이용이 용이한 지역으로서 도심 내 소형주택의 공급 확대, 토지의 고도이용과 건축물의 복합개발이 필요한 지구

2-3-2 추진과정

○ 타부처(관계기관)와 협의나 전문가 자문 등에 소요되는 기간은 과업수행기간에서 제외하여 그 소요기간 만큼 과업수행기간을 연장하여야 한다.

1. 재정비촉진지구의 지정절차

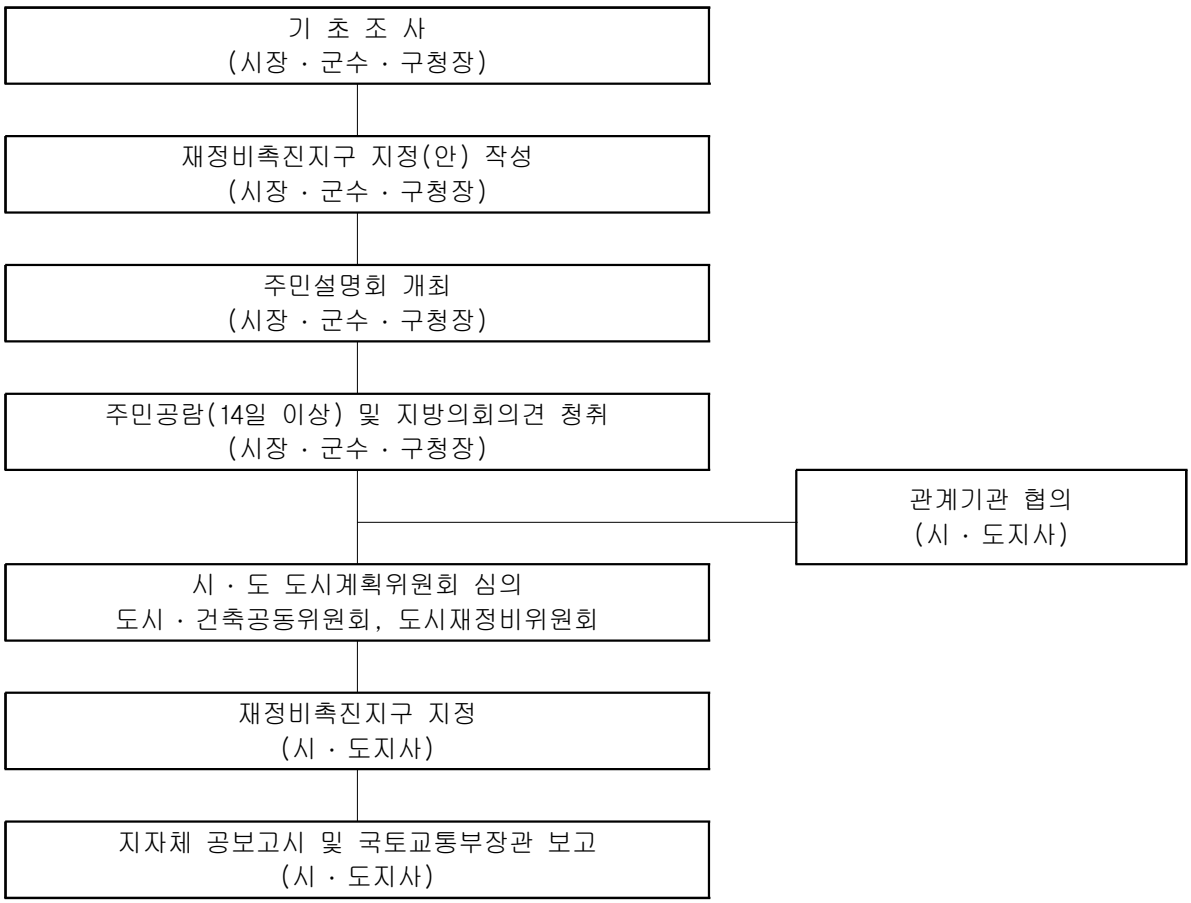

2. 재정비촉진계획의 수립절차

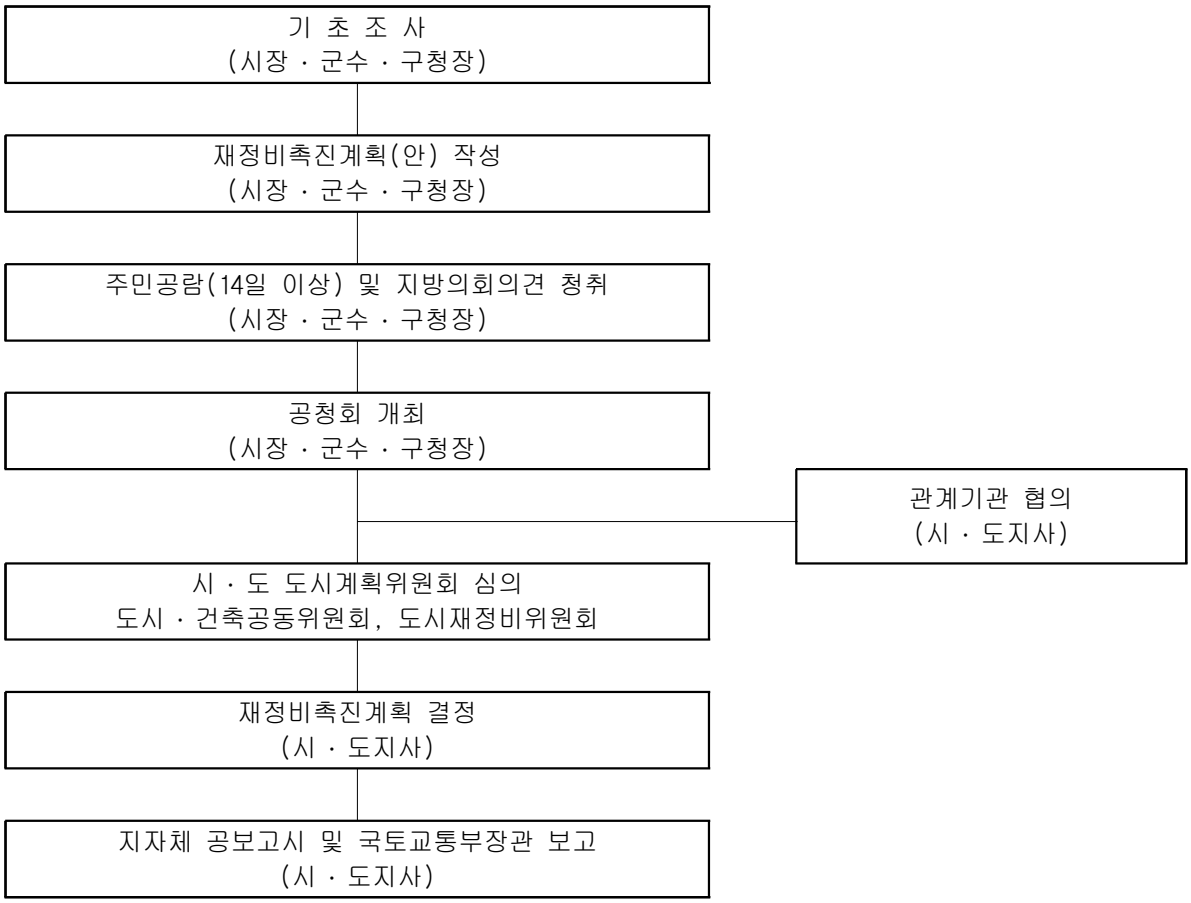

2-4 품 산정의 원단위 산정과 기준

2-4-1 표준품 산정내역

○ 표준품 산정의 기준이 되는 비목은 제1장 총칙에서 제시한 비목을 중심으로 하였으며, 이는 재정비촉진계획에 필요한 사항만을 대상으로 한다.

○ 표준품 산정의 기본이 되는 직접인건비 품의 작업항목별 보할은 업무의 난이도를 감안하여 설정토록 한다.

1. 재정비촉진지구 지정

종 별		내 용	세부항목	단 위	비 고
직접비	직접인건비	1.기초조사	①도시현황조사 ②관련계획조사 ③교통관계조사 ④시설관계조사 ⑤공급처리시설 관계조사	인·일 〃 〃 〃 〃	
		2.기본구상	①지구의 개요 및 목적 ②지구의 지정요건 분석 ③개발의 기본방향 ④추진사업의 현황 ⑤기반시설 설치에 관한 사항 ⑥기타 지구의 지정에 관한 사항	〃 〃 〃 〃 〃 〃	
		3.성과품작성	①보고서작성 및 편집 ②관련도서작성	〃 〃	
		4.기술협의	①공청회 / 주민설명회 ②주민간담회 / 시민계획단 ③위원회심의 지원 ④관계기관 협의	〃 〃 〃 〃	
	직접경비	여비, 인쇄비, 조감도, 회의준비비, 현장운영비 등		식	제1장 총칙참조
간접비	제경비	(직접인건비)×120%		〃	〃
	기술료	(직접인건비+제경비)×30%		〃	〃

2. 재정비촉진계획

종 별		내 용	세부항목	단 위	비 고
직접비	직접인건비	1.기초조사	①도시현황조사	인·일	
			②관련계획조사	〃	
			③교통관계조사	〃	
			④시설관계조사	〃	
			⑤공급처리시설 관계조사	〃	
		2.기본계획	①기본방향	〃	
			②정비의 기본방향 및 목표	〃	
			③토지 이용에 관한 계획	〃	
			④인구 · 주택 수용계획	〃	
			⑤기반시설 설치계획	〃	
			⑥공원 · 녹지 조성 및 환경보전 계획	〃	
			⑦교통계획	〃	
			⑧경관계획	〃	
			⑨촉진구역 지정에 관한 사항	〃	
			⑩재정비촉진사업별 건축계획	〃	
			⑪기반시설의 비용분담계획	〃	
			⑫세입자 등의 주거대책	〃	
			⑬범죄예방대책	〃	
			⑭단계적 사업 추진에 관한 사항	〃	
			⑮상가의 분포 및 수용계획	〃	
			⑯계획의 수립기준에 관한 사항	〃	
		3.성과품작성	①보고서작성 및 편집	〃	
			②관련도서작성	〃	
		4.기술협의	①공청회 / 주민설명회	〃	
			②주민간담회 / 시민계획단	〃	
			③위원회심의 지원	〃	
			④관계기관 협의	〃	
	직접경비	여비, 인쇄비, 조감도, 회의준비비, 현장운영비 등		식	제1장 총칙참조
간접비	제경비	(직접인건비)×120%		〃	〃
	기술료	(직접인건비+제경비)×30%		〃	〃

2-4-2 산정기준

1. 계획·기준면적의 설정

○ 사업의 조사설계산정의 원단위 책정을 마련하기 위하여 기준면적을 다음과 같이 설정한다.

구 분	주거지형	중심지형	고밀복합형
기준면적	50만㎡	20만㎡	10만㎡

○ 계획면적은 과정별 업무성격에 따라 과업지구면적을 기준으로 산정한다.

2. 표준품의 산정방법

○ 표준품의 적용에 있어 기준면적과 계획면적의 차이에 따른 품 산정은 아래의 수정식에 따라 기준면적의 소요작업량을 수정하여 산정한다.

○ 소요작업량 = 기준면적소요작업량×면적보정계수(α, β, γ)×계획별보정계수(π, ζ)

○ 업무에 필요한 자료는 자료제공의 전제에 따라 발주자의 제공이 불가능하여 엔지니어링사업자에게 작성토록 할 경우 그의 내용에 따라 실비로 계상한다.

○ 업무의 수행에 필요한 각종 평가업무(교통, 환경, 재해, 경관)는 제8장 도시평가의 해당 품을 별도 적용하며, 측량·전산처리·시험 등의 경비에 대하여는 실비로 가산한다.

○ 사업시행인가(고시)용 계획 및 건축배치계획 등 보다 상세한 계획이 요구될 때에는 업무의 범위로 보아 그 소요되는 작업량의 산정은 토목설계의 경우 제5장 3절 주택단지개발계획에 준하며, 건축설계의 경우는 제4장 제1절 지구단위계획의 건축물에 관한 계획의 품을 준용한다.

○ 재정비촉진계획의 기초조사는 도시· 주거환경정비기본계획의 해당품을 적용한다.

○ 재정비촉진계획의 수립시 존치관리구역에 대한 관리계획을 수립하여야 하는 경우에는 제4장 제1절의 지구단위계획의 품을 준용한다.

3. 계획안의 수정과 과업중지에 따른 품 산정방법

○ 계획안이 작성되고 주민공람, 의회보고, 공청회 등 기술협의과정을 거쳐 계획안이 확정된 후 발주자의 사정에 의하여 계획안이 일부변경 · 재작업이 수행되는 경우에는 그 변경·중지·재작업의 정도에 따라 엔지니어링사업대가의 50～100% 수준에서 비용을 추가 지급하여야 한다.

○ 과업수행 중 발주자의 사정에 따른 과업 중단으로 인해 정부 회계연도가 경과되어 현저한 비용의 차이가 발생하였을 경우에는 엔지니어링사업대가를 당해 신년도의 노임단가를 기준으로 재산정하여야 한다.

1-4-3 단위별 변화수정과 보정

1. 작업량 보정계수 산정

1) 면적의 대소에 대한 작업량 보정계수 산정

○ 재정비촉진계획 면적이 기준면적을 초과하거나 못 미치는 경우의 직접인력 소요작업량의 산정을 위한 보정계수(α, β, γ)는 다음과 같이 산정한다.

$$\alpha, \beta, \gamma = \left(\frac{\text{계획면적}}{\text{기준면적}}\right)^{0.6} = \left(\frac{A}{50}\right)^{0.6}$$

α = 보정계수
A = 계획면적(만㎡)

○ 최소계획면적은 주거지형(α)15만㎡, 중심지형(β)·고밀복합형(γ)은 10만㎡에 준한다.

2)재정비촉진계획 종류에 대한 작업량 보정계수 산정

○ 재정비촉진계획의 주거지형과 중심지형, 고밀복합형은 계획의 성격상 업무내용과 범위에서 큰 차이를 보이므로, 중심지형과 고밀복합형에 대하여는 작업량 보정 계수를 다음과 같이 설정하여 적용한다.

구 분	보정계수(π)
주거지형	1.0
중심지형	1.3
고밀복합형	1.5

3) 인구밀도의 변화에 따른 수정

$$\zeta = (0.55+0.003P)$$

ζ = 보정계수
P = 인구밀도(인 / ha)

P	1,000	800	600	500	400	300	250	200	150	100
ζ	3.55	2.95	2.35	2.05	1.75	1.45	1.3	1.15	1	0.85

계획면적에 대한 작업량 보정계수

면적(A) 만㎡	보정계수				
	주거지형 (α)	중심지형 (β)	고밀복합형 (r)	계획종류 (π)	인구밀도의 변화 (ζ)
10.0	0.485	0.381	0.381	1.0 / 1.3 / 1.5	0.55+ 0.003P
15.0	0.485	0.485	0.485		
20.0	0.577	0.577	0.577		
25.0	0.660	0.660	0.660		
30.0	0.736	0.736	0.736		
40.0	0.875	0.875	0.875		
50.0	1.000	1.000	1.000		
60.0	1.116	1.116	1.116		
70.0	1.224	1.224	1.224		
80.0	1.326	1.326	1.326		
90.0	1.423	1.423	1.423		
100.0	1.516	1.516	1.516		
150.0	1.933	1.933	1.933		
200.0	2.297	2.297	2.297		
300.0	2.930	2.930	2.930		
400.0	3.482	3.482	3.482		

2. 직접인건비 소요 작업량 산정

○ 계획면적의 대소에 따른 직접인력 소요작업량의 산정방법은 아래와 같이 기준면적의 직능별 직접인력 소요작업량에 계획단위 보정계수(α, β, γ, π, ζ)을 곱하여 산출한다.

구 분	기준면적 (만㎡)	총작업량(인·일)					
		기술사	특 급	고 급	중 급	초 급	보조원
촉진 지구	50	37.5α(β, γ)πζ	60.4α(β, γ)πζ	139.5α(β, γ)πζ	234.2α(β, γ)πζ	333.8α(β, γ)πζ	326.8α(β, γ)πζ
촉진 계획	50	59.3α(β, γ)πζ	95.9α(β, γ)πζ	208.3α(β, γ)πζ	353.1α(β, γ)πζ	505.6α(β, γ)πζ	500.4α(β, γ)πζ

2-5 표준단위 업무분류와 원단위

2-5-1 재정비촉진지구 지정

기술업무의 직능별 직접인력 소요작업량(면적 50만㎡ 기준)

(단위 : 인·일/표준단위)

구 분	업무내용	표준단위	소요인력						비고
			기술사	특 급	고 급	중 급	초 급	보조원	
1.현황조사	①도시현황조사	50만㎡	3.5	5.7	23.8	35.9	59.6	64.4	
	②관련계획조사	50만㎡	1.3	2.1	2.8	7.8	7.8	10.5	
	③교통관계조사	50만㎡	1.5	2.3	5.2	10.5	10.2	10.5	
	④시설관계조사	50만㎡	1.5	2.3	7.8	10.7	13.1	13.3	
	⑤공급처리시설 관계조사	50만㎡	1.3	2.1	5.5	7.8	8.4	7.8	
	소 계		9.1	14.5	45.1	72.7	99.1	106.5	
2.기본구상	①지구의 개요 및 목적	50만㎡	3.0	4.8	9.6	15.8	23.8	15.2	
	②지구의 지정요건 분석	50만㎡	2.1	3.5	6.4	10.9	16.0	15.2	
	③개발의 기본방향	50만㎡	3.0	4.8	9.6	16.0	23.8	22.8	
	④추진사업의 현황	50만㎡	2.5	4.1	8.1	13.4	19.6	19.0	
	⑤기반시설 설치에 관한 사항	50만㎡	8.3	13.2	27.0	44.6	66.0	63.3	
	⑥기타 지구의 지정에 관한 사항	50만㎡	2.5	4.1	8.1	13.4	19.6	19.0	
	소 계		21.4	34.5	68.8	114.1	168.8	154.5	
3.성과품작성	①보고서작성 및 편집	50만㎡	4.8	7.5	17.0	28.3	28.1	18.6	
	②관련도서작성	50만㎡	2.2	3.9	8.6	19.1	37.8	47.2	
	소 계		7.0	11.4	25.6	47.4	65.9	65.8	
총 계			37.5	60.4	139.5	234.2	333.8	326.8	
4.기술협의	①공청회/주민설명회	1식	2.0	2.0	2.0	4.0	4.0	4.0	주1
	②주민간담회/시민계획단	1식	2.0	2.0	2.0	4.0	4.0	4.0	
	③위원회심의 지원	1식	2.0	2.0	2.0	4.0	4.0	4.0	
	④관계기관 협의	1식	2.0	2.0	2.0	4.0	4.0	4.0	
	소 계		8.0	8.0	8.0	16.0	16.0	16.0	

주 : ①기술협의는 2회 이내 기준이며, 횟수가 늘어날 경우 증가배수에 해당하는 작업품과 비용을 가산한다. (필요항목 선택적 적용)

②각종영향성검토 및 각종영향평가업무는 별도의 엔지니어링활동업무로 계상한다.

③표준단위면적은 "2-4-2 산정기준의 1.계획·기준면적의 설정" 준용

2-5-2 재정비촉진계획

기술업무의 직능별 직접인력 소요작업량(면적 50만㎡ 기준)

(단위 : 인·일/표준단위)

구 분	업무내용	표준단위	소요인력						비고
			기술사	특급	고급	중급	초급	보조원	
1.현황조사	①도시현황조사	50만㎡	3.5	5.7	23.8	35.9	59.6	64.4	
	②관련계획조사	50만㎡	1.3	2.1	2.8	7.8	7.8	10.5	
	③교통관계조사	50만㎡	1.5	2.3	5.2	10.5	10.2	10.5	
	④시설관계조사	50만㎡	1.5	2.3	7.8	10.7	13.1	13.3	
	⑤공급처리시설 관계조사	50만㎡	1.3	2.1	5.5	7.8	8.4	7.8	
	소 계		9.1	14.5	45.1	72.7	99.1	106.5	
2.기본계획	①기본방향	50만㎡	2.7	4.4	8.7	14.4	21.6	13.8	주1
	②정비의 기본방향 및 목표	50만㎡	2.3	3.6	7.1	12.0	16.8	20.0	
	③토지 이용에 관한 계획	50만㎡	2.7	4.4	8.7	14.6	21.6	20.7	
	④인구 · 주택 수용계획	50만㎡	2.3	3.8	7.4	12.2	17.9	17.3	
	⑤기반시설 설치계획	50만㎡	2.3	3.8	5.9	9.9	18.0	17.3	
	⑥공원 · 녹지 조성 및 환경보전 계획	50만㎡	2.7	4.4	8.7	14.6	21.6	13.8	
	⑦교통계획	50만㎡	2.7	4.4	8.7	14.6	21.6	13.8	
	⑧경관계획	50만㎡	2.3	3.8	7.1	11.9	16.8	20.0	
	⑨촉진구역 지정에 관한 사항	50만㎡	2.3	3.8	7.1	11.9	16.8	20.0	
	⑩재정비촉진사업별 건축계획	50만㎡	2.7	4.4	8.7	14.6	21.6	20.7	
	⑪기반시설의 비용분담계획	50만㎡	2.3	3.6	7.1	11.9	16.8	20.0	
	⑫세입자 등의 주거대책	50만㎡	2.3	3.8	7.4	12.2	17.9	17.3	
	⑬범죄예방대책	50만㎡	2.3	3.6	7.2	12.2	17.9	17.3	
	⑭단계적 사업추진에 관한 사항	50만㎡	2.3	3.6	7.1	11.9	16.8	20.0	
	⑮상가의 분포 및 수용계획	50만㎡	2.3	3.6	7.4	12.2	17.9	17.6	
	⑯계획의 수립기준에 관한 사항	50만㎡	2.3	3.8	7.4	12.2	17.9	17.3	
	소 계		38.8	62.8	121.7	203.3	299.5	286.9	
3.성과품작성	①보고서작성 및 편집	50만㎡	7.8	12.2	27.6	46.0	45.6	30.3	
	②관련도서작성	50만㎡	3.6	6.4	13.9	31.1	61.4	76.7	
	소 계		11.4	18.6	41.5	77.1	107.0	107.0	
총 계			59.3	95.9	208.3	353.1	505.6	500.4	
4.기술협의	①공청회/주민설명회	1식	2.0	2.0	2.0	4.0	4.0	4.0	주2
	②주민간담회/시민계획단	1식	2.0	2.0	2.0	4.0	4.0	4.0	
	③위원회심의 지원	1식	2.0	2.0	2.0	4.0	4.0	4.0	
	④관계기관 협의	1식	2.0	2.0	2.0	4.0	4.0	4.0	
	소 계		8.0	8.0	8.0	16.0	16.0	16.0	

주 : ①경관심의 및 지구경관계획은 제7장 경관계획의 엔지니어링 품을 별도 계상한다.

②기술협의는 2회 이내 기준이며, 횟수가 늘어날 경우 증가배수에 해당하는 작업품과 비용을 가산한다. (필요항목 선택적 적용)

③각종영향성검토 및 각종영향평가업무는 별도의 엔지니어링활동업무로 계상한다.

④표준단위면적은 "2-4-2 산정기준의 1.계획·기준면적의 설정" 준용

2-5-3 조사측량

○ 측량품을 별도 적용한다.

2-5-4 토질조사 및 시험

○ 토질조사 및 시험품을 별도 적용한다.

2-5-5 기본설계 및 실시설계

○ 기본설계 및 실시설계의 산출기준은 엔지니어링사업대가의 기준 중 건설부문 공사비 요율을 적용한다.

2-6 주요업무내용

2-6-1 재정비촉진지구 지정

구 분	업무내용	내 용
1.현황조사	①도시현황조사	·자연현황(표고분석, 경사도 분석) ·토지이용현황(지목별, 소유자별, 필지 규모별, 공시지가별, 필지별 세입자·가구수 현황) ·건축물 현황(층수별, 경과년수별, 용적률, 용도별 현황) ·도시·군관리계획 현황(가로망체계, 도시·군관리계획, 용도지역, 상수도, 우수·오수 현황) ·도시 및 주거환경정비기본계획상 대상지 주변 개발사업 예정지 현황 ·지구 및 주변지역 현황 - 지형 및 지세(표고, 경사, 기상) - 인문·사회 현황(인구 및 가구, 주택, 주택소유) - 산업·경제 현황(사업체수, 산업별 사업체수, 종사자수, 사업체 규모별 종사자수) ·대상지 및 주변지역 특성 - 대상지 주변 현황, 대상지 내부 현황
	②관련계획조사	·상위계획 및 관련 법규 검토
	③교통관계조사	·가로망체계, 도로 등 교통 현황
	④시설관계조사	·공원·녹지, 학교 및 공공시설
	⑤공급처리시설 관계조사	·상수도, 우수·오수 현황 등 기반시설 현황
2.기본구상	①지구의 개요 및 목적	·지구의 명칭, 위치, 면적 ·기준연도, 목표연도 ·지정 및 계획의 목적 ·지구계 결정사유
	②지구의 지정 요건분석	·해당 지구유형의 지정요건에 대한 적합성분석

구 분	업무내용	내 용
2.기본구상 (계속)	③개발의 기본 방향	·지정배경, 개발방향, 개발목표, 과업수행절차 ·기본구상(안)도
	④추진사업의 현황	·재정비촉진지구에서 시행 중인 재정비촉진사업의 현황
	⑤기반시설 설치에 관한 사항	·계획지표 설정 (인구 및 세대수, 공원·녹지, 학교, 주차장) ·기반시설 설치계획(안) ·단계별 사업계획(안)(연도별 노후불량률 검토)
	⑥기타지구의 지정에 관한 사항	·부동산 투기 대책 ·지구범위, 지구유형 요건 ·목표연도 ·공간적 위치, 재정비촉진지구의 특성 ·재정비촉진 필요성 ·주변 지역의 주택보급률 등 주택수급 현황 ·기존 국공유지 및 기반시설의 정의 ·인구구성 · 인구이동 현황 및 변화추이 ·각종 개발사업 계획

2-6-2 재정비촉진계획

구 분	업무내용	내 용
1.현황조사	①도시현황조사	·지역별·산업별·연령별 인구의 구성, 인구이동현황 및 변화추이 ·지역총생산액, 지역별 산업체수 및 종사자수 변화추이 ·문화재, 역사적 유물 또는 전통건물, 기타 문화자원 등 인문환경 ·고도분석과 경사도분석 및 수계분석, 하천별수량, 수변여건 등 ·공원·녹지 현황 및 보존 필요성이 있는 수목 등 자연환경 ·상습침수구역 등 재해 관련 현황 ·토지의 지목, 소유자, 필지규모, 공시지가 등 현황 ·토지 및 건축물의 용도별 현황 ·노후·불량건축물정도, 주택밀도, 주택접도율 등 ·주택수, 세대수 및 거주자수 (세입자포함) ·주택재개발·주택재건축 임대주택 및 공공임대주택 현황 ·주택의 경과년수 (무허가건축물포함) ·가구별 소득수준 및 직업형태 ·주택의 규모 및 거주 형태 (자가, 전세, 월세), 주택가격 및 임대료 수준 ·주택규모와 임대료 수준 등을 포함한 임대주택 희망수요, 주택규모와 분양가격 수준 등을 포함한 소형분양주택 희망수요 ·인근지역의 이주 희망수요
	②관련계획조사	·도시·군기본계획 및 관련계획 ·도시정책방향, 도시공간구조 등 ·각종 개발계획 및 개발사업 현황 ·도시 및 주거환경정비기본계획상의 정비예정구역 등 관련계획 ·도시·군관리계획검토(용도지역, 용도구역, 용도지구, 도시·군계획시설 등) ·토지거래허가구역 등 현황 ·일자리 현황 (소득수준별, 연령별, 업종별 등)
	③교통관계조사	·도로 등 기반시설 및 교통 현황

구 분	업무내용	내 용
1.현황조사	④시설관계조사	·공공·문화체육시설, 교육시설, 공간시설 등의 현황 및 지역별 편재정도 ·공원·녹지체계 현황
	⑤공급처리시설 관계조사	·상수도 등 기반시설 현황
2.촉진계획	①기본방향	·지정 배경 및 개발 방향 ·개발목표 및 과업수행절차 ·계획의 위상 및 성격 정립 ·재정비촉진지구의 역할 및 기능
	②정비의 기본 방향및 목표	·기본방향설정 및 계획의 목표 및 실천 전략 ·주요 계획지표 설정 ·공간구조구상, 생활권 구상 ·토지이용구상 ·동선체계구상 ·공원녹지체계구상
	③토지이용에 관한 계획	·기본방향 ·거점개발, 생활권, 오픈스페이스, 토지이용계획
	④인구·주택 수용계획	·기본방향, 현황 인구 및 세대수 ·기존 건축물 호수, 인구 및 주택수용 계획 ·구역별 인구 및 주택수용 계획
	⑤기반시설 설치계획	·기본방향 및 기반시설 설치 계획 ·학교, 문화·복지시설 ·기타 시설 (상수도·우수처리·오수처리·전력·통신 계획)
	⑥공원·녹지 조성 및 환경보전계획	·기본방향, 공원·녹지계획 ·공원·녹지 및 환경보전계획
	⑦교통계획	·기본구상 및 교통계획 ·생활권, 보행, 자전거, 대중교통 계획 ·도로의 위계 및 기능, 도로 조성 계획
	⑧경관계획	·기본방향 및 경관형성의 기본시점 ·주요 공간별 경관특성화 계획
	⑨촉진구역 지정에 관한 사항	·기본방향 ·재정비촉진구역 지정대상 사업 ·재정비촉진구역 지정 요건, 사업의 종류
	⑩재정비촉진 사업별 건축 계획	·기본방향 및 건축계획, 건축선에 관한 계획 ·주거시설 건축 가이드라인 ·구역별 건축계획 기준, 권역별 높이계획 구상 ·건축물의 용도 및 건폐율·용적률·높이 계획 ·구역별 건폐율·용적률·높이 등의 건축계획
	⑪기반시설의 비용 분담 계획	·기본방향 및 기반시설 비용분담계획 ·기존 국공유지 및 기반시설의 정의 ·촉진지구 전체 기반시설 확보율 ·촉진구역별 기반시설 순부담률 산정 ·촉진구역별 기반시설 분담계획

구 분	업무내용	내 용
2.촉진계획 (계속)	⑫세입자 등의 주거대책	·기본방향 및 관련 법령, 임대주택 공급계획 ·소유자 재정착 대책(원거주민) ·세입자 재정착 대책(세입자)
	⑬범죄예방대책	·재정비촉진사업 시행기간 동안의 범죄예방대책
	⑭단계적 사업 추진에 관한 사항	·기본방향 및 단계별 사업추진 계획
	⑮상가의 분포 및 수용계획	·상가의 분포 및 수용계획
	⑯계획의 수립 기준에 관한 사항	·재정비촉진계획 수립기준에 관한 사항

2-7 표준성과품

2-7-1 재정비촉진지구 지정

성과 구분	표준성과도서			비 고
	구 분	규 격	제출부수	
현황도	·토지이용 현황도 ·건물 현황도 ·도시시설 현황도	1/3,000 또는 1/500 〃 〃	1부 〃 〃	지구지정시 현황측량이 필요할 경우 발주자와 협의하여 별도 작성제출
설계도	·재정비촉진지구 총괄도 ·재정비촉진지구 표시도	1/3,000 또는 1/5,000	1부 〃	도시별 적정축척 사용
보고서	·재정비촉진지구 계획 보고서 ·기초조사 및 계획수립 관련 자료집	발주자와 협의 결정	발주자와 협의결정	

주 : ①제출부수 및 성과품 종류가 증가할 경우에는 증가배수에 해당하는 작업품과 비용을 가산한다.
②계획보고서 및 기타 관련자료의 규격 및 제출부수는 발주자와의 협의에 의하여 비용을 산정한다.

2-7-2 재정비촉진계획

성과구분	표준성과도서			비 고
	구 분	규 격	제출부수	
현황도	·토지이용 현황도 ·건물 현황도 ·도시시설 현황도	1/3,000 또는 1/500 〃 〃	1부 〃 〃	
계획도	·토지이용 계획도 ·재정비촉진지구 계획도 ·도시·군계획시설 계획도 ·종합 계획도	1/3,000 또는 1/500 〃 〃 〃	〃 〃 〃 〃	
보고서	·계획 보고서	발주자와 협의결정	발주자와 협의결정	
조감도	·계획구역 조감도	발주자와 협의결정	1식	지역규모에 따라 조정가능

주 : ①제출부수 및 성과품 종류가 증가할 경우에는 증가배수에 해당하는 작업품과 비용을 가산한다.
②계획보고서 및 기타 관련자료의 규격 및 제출부수는 발주자와의 협의에 의하여 비용을 산정한다.

제3절 도시 및 주거환경정비계획

3-1 정 의

○ 도시의 기능회복이 필요하거나 주거환경이 불량한 지역을 계획적으로 정비하고 노후·불량 건축물을 효율적으로 개량하기 위하여 필요한 사항을 규정하여, 도시환경을 개선하고 주거생활의 질을 높이고자 하는 사업을 말한다.

3-2 자료제공의 전제

○ 당해 계획의 수립에 필요한 모든 관련자료는 원칙적으로 발주자가 제공하는 것으로 하되, 발주자가 보유하지 않는 자료는 엔지니어링사업자가 조사·수집한다.

○ 발주자가 제공하지 못하는 자료의 조사에 있어서는 그 규모·내용에 의거하여 별도의 엔지니어링사업대가를 산정하여 엔지니어링사업자가 수행하며, 당해 관련자료의 기밀성과 광범위한 자료가 요구될 경우에는 조사·분석에 필요한 상당기간과 자료수집비용이 전제되어야 한다.

3-3 업무범위와 추진과정

3-3-1 업무범위

1. 정비사업의 범위

① 주거환경개선사업 : 도시저소득주민이 집단으로 거주하는 지역으로서 정비기반시설이 극히 열악하고 노후·불량건축물이 과도하게 밀집한 지역에서 주거환경을 개선하기 위하여 시행하는 사업

② 주택재개발사업 : 정비기반시설이 열악하고 노후·불량건축물이 밀집한 지역에서 주거환경을 개선하기 위하여 시행하는 사업

③ 주택재건축사업 : 정비기반시설은 양호하나 노후·불량건축물이 밀집한 지역에서 주거환경을 개선하기 위하여 시행하는 사업

④ 도시환경정비사업 : 상업지역·공업지역 등으로서 토지의 효율적 이용과 도심 또는 부도심 등 도시기능의 회복이 필요한 지역에서 도시환경을 개선하기 위하여 시행하는 사업

⑤ 주거환경관리사업 : 단독주택 및 다세대주택 등이 밀집한 지역에서 정비기반시설과 공동이용시설의 확충을 통하여 주거환경을 보전・정비・개량하기 위하여 시행하는 사업

⑥ 가로주택정비사업 : 노후・불량건축물이 밀집한 가로구역에서 종전의 가로를 유지하면서 소규모로 주거환경을 개선하기 위하여 시행하는 사업

2. 정비사업의 업무범위

○ 정비사업의 업무범위는 정비구역의 지정에서부터 사업완료에 이르기까지의 기술관리, 처분업무의 입안 작성 및 인허가 과정을 망라하는 조사, 측량, 기본계획, 사업계획, 관리처분계획, 공사설계, 등기, 정산, 보상, 자문, 감리 등을 포함한다.

3-3-2 추진과정

○ 타부처(관계기관)와 협의나 전문가 자문 등에 소요되는 기간은 과업수행기간에서 제외하여 그 소요기간 만큼 과업수행기간을 연장하여야 한다.

1. 도시 · 주거환경정비 기본계획의 수립절차

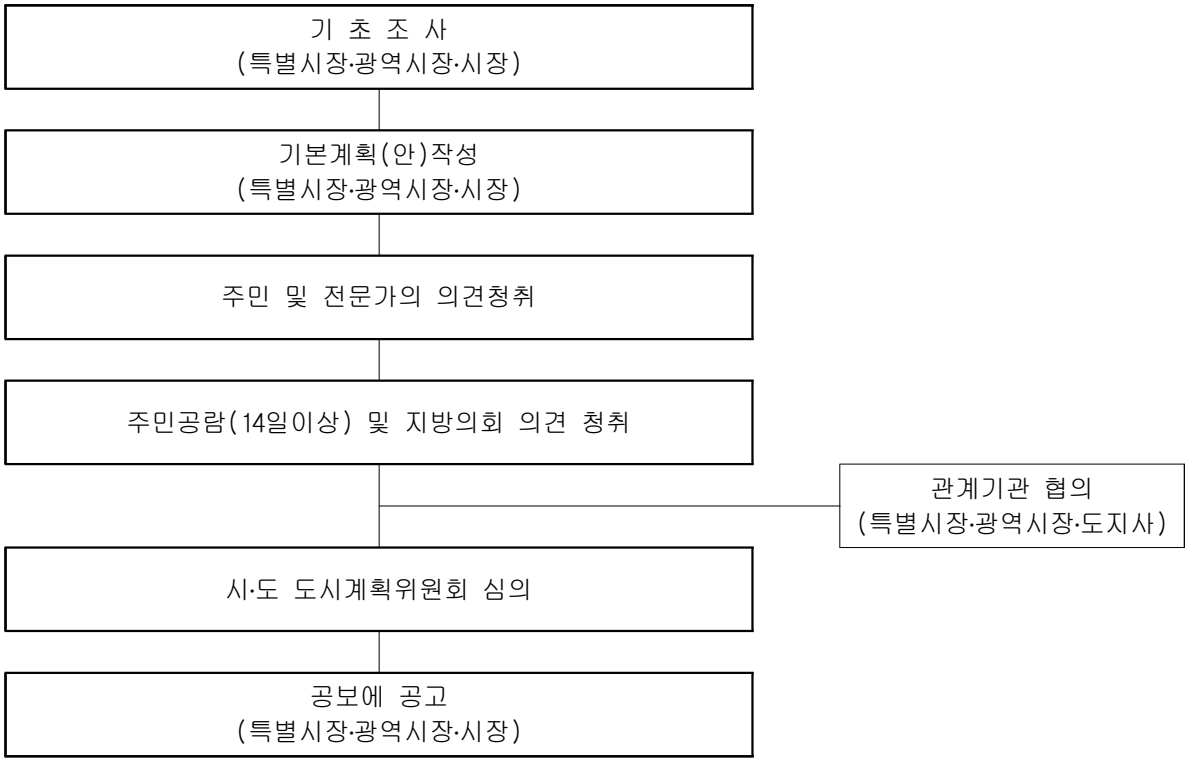

2. 과업 수행 추진과정

정비사업의 추진절차

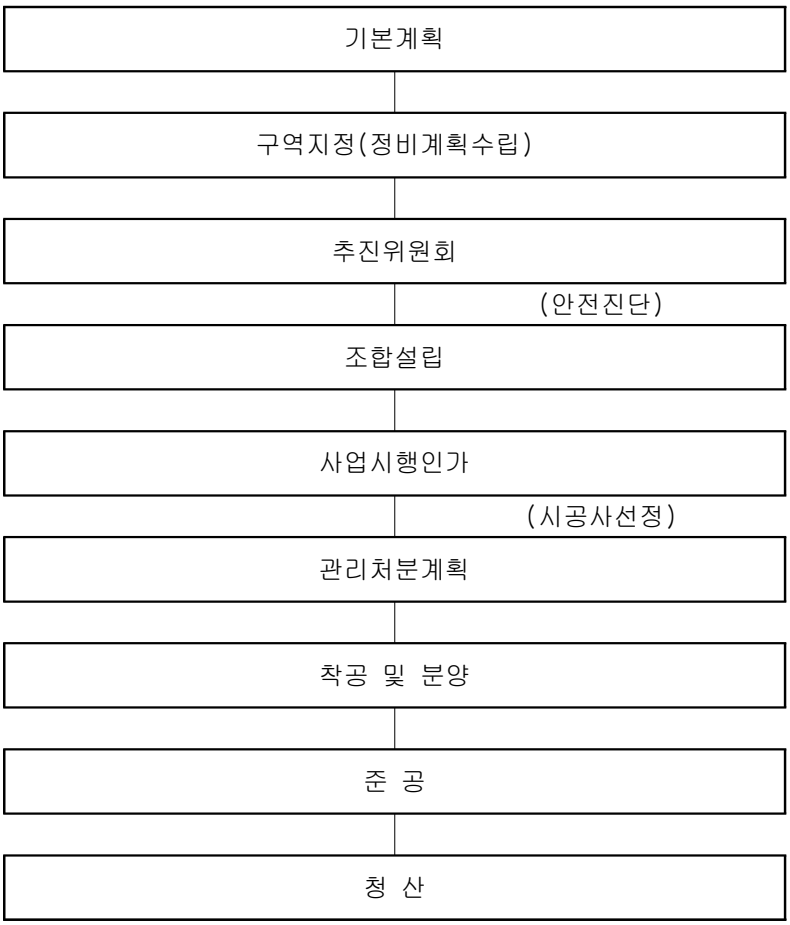

주 : ① 주거환경개선사업의 경우 조합설립, 관리처분계획 절차가 없음
② 주거환경관리사업의 경우 추진위원회 구성, 조합설립, 관리처분계획 절차가 없음
③ 가로주택정비사업의 경우 정비기본계획수립, 추진위원회 구성, 구역지정(정비계획) 수립 절차가 없음

3-4 품 산정의 원단위 산정과 기준

3-4-1 표준품 산정내역

○ 표준품 산정의 기준이 되는 비목은 제1장 총칙에서 제시한 비목을 중심으로 하였으며, 이는 도시· 주거환경정비계획수립에 필요한 사항만을 대상으로 한다.

○ 표준품 산정의 기본이 되는 직접인건비 품의 작업항목별 보할은 업무의 난이도를 감안하여 설정토록 한다.

1. 도시·주거환경정비 기본계획

종 별		내 용	세부항목	단 위	비 고
직접비	직접인건비	1.기초조사	①도시현황조사 ②관련계획조사 ③교통관계조사 ④시설관계조사 ⑤공급처리시설 관계조사	인·일 〃 〃 〃 〃	
		2.기본계획	①기본원칙 ②정비예정구역의 설정 ③도심기능의 활성화 및 도심공동화 방지 방안 ④주거지 관리계획 ⑤공공과 민간의 역할 분담계획 ⑥재원조달 계획 ⑦단계별 추진계획 ⑧사업지구내 거주민 주거안정대책 ⑨정비예정구역의 관리계획 ⑩토지이용계획 ⑪정비기반시설계획 및 공동이용시설 설치계획 ⑫교통계획 ⑬환경계획 ⑭사회복지 및 주민문화시설 등의 설치계획 ⑮건폐율·용적률 등에 관한 건축물의 밀도계획 ⑯역사적 유물 및 전통건축물 보존 및 활용계획 ⑰도시경관에 관한 계획	〃 〃 〃 〃 〃 〃 〃 〃 〃 〃 〃 〃 〃 〃 〃 〃 〃 〃	
		3.성과품작성	①보고서작성 및 편집 ②관련도서 작성	〃 〃	
		4.기술협의	①공청회 / 주민설명회 ②주민간담회 / 시민계획단 ③위원회심의 지원 ④관계기관 협의	〃 〃 〃 〃	
	직접경비	여비, 인쇄비, 조감도, 회의준비비, 현장운영비 등		식	제1장 총칙 참조
간접비	제경비	(직접인건비)×120%		〃	〃
	기술료	(직접인건비+제경비)×30%		〃	〃

2. 구역지정(정비계획)

1) 주택재개발사업·주택재건축사업·도시환경정비사업

종 별		내 용	세부항목	단 위	비 고
직접비	직접인건비	1.현황조사	①주민·산업의 현황 ②토지·건축물의 이용·소유현황 ③정비기반시설의 설치현황 ④정비구역·주변지역의 교통상황 ⑤토지·건축물의 가격·임대차 현황 ⑥정비사업에 대한 주민의 의견	인·일 〃 〃 〃 〃 〃	
		2.정비계획	①계획의 수립방향 ②정비사업의 시행 계획 ③토지이용계획 ④정비기반시설의 설치 계획 ⑤공동이용시설 설치계획 ⑥기존 건축물의 정비·개량 계획 ⑦건축물 계획 ⑧교통·동선처리계획 ⑨환경보전·재난방지 계획 ⑩구역 주변의 교육환경 보호 계획 ⑪구역의 분할·결합에 관한 계획 ⑫주택수급에 관한 사항 ⑬세입자 주거대책 ⑭안전·범죄예방 사항	〃 〃 〃 〃 〃 〃 〃 〃 〃 〃 〃 〃 〃 〃	
		3.성과품작성	①보고서작성 및 편집 ②관련도서 작성	〃 〃	
		4.기술협의	①공청회 / 주민설명회 ②주민간담회 / 시민계획단 ③위원회 심의 지원 ④관계기관 협의	〃 〃 〃 〃	
	직접경비	여비, 인쇄비, 조감도, 회의준비비, 현장운영비 등		식	제1장 총칙참조
간접비	제경비	(직접인건비)×120%		〃	〃
	기술료	(직접인건비+제경비)×30%		〃	〃

2) 주거환경개선사업

종 별		내 용	세부항목	단 위	비 고
직접비	직접인건비	1.현황조사	①토지이용현황조사	인·일	
			②건물현황조사	〃	
			③인구 및 산업현황조사	〃	
			④도시시설 설치 현황조사	〃	
			⑤교통관계조사	〃	
			⑥공급처리시설 관계조사	〃	
			⑦주민생활형편 조사	〃	
		2.기본구상	①기초조사·분석	〃	
			②개발정비조건 및 내용설정	〃	
			③구상안 작성	〃	
			④기술적 타당성 검토	〃	
			⑤경제적 타당성 검토	〃	
		3.기본계획	①토지이용계획	〃	
			②공공시설정비계획	〃	
			③주택의 건설 및 부대, 복리시설계획	〃	
			④건축물의 개량	〃	
			⑤관리운영계획	〃	
			⑥기타계획	〃	
		4.성과품작성	①보고서작성 및 편집	〃	
			②관련도서작성	〃	
		5.기술협의	①공청회 / 주민설명회	〃	
			②주민간담회 / 시민계획단	〃	
			③위원회심의 지원	〃	
			④관계기관 협의	〃	
	직접경비	여비, 인쇄비, 조감도, 회의준비비, 현장운영비 등		식	제1장 총칙참조
간접비	제경비	(직접인건비)×120%		〃	〃
	기술료	(직접인건비+제경비)×30%		〃	〃

3) 주거환경관리사업

종 별		내 용	세부항목	단 위	비 고
직접비	직접인건비	1.현황조사	①도시계획현황 및 지형현황	인·일	
			②토지이용현황	〃	
			③건축물현황	〃	
			④인구 및 산업현황	〃	
			⑤정비사업에 대한 주민의 의견	〃	
			⑥가로시설물 및 조경환경	〃	
			⑦자연환경 및 생활환경	〃	
			⑧교통관련현황	〃	
			⑨도시시설 설치현황	〃	
		2.기본구상	①정비목표 및 구현전략의 설정	〃	
			②기본방향 및 지표설정	〃	
		3.부문별계획	①토지이용계획	〃	
			②공동이용시설 설치계획	〃	
			③주민공동체 활성화 방안	〃	
			④주거환경관리사업 시행계획	〃	
			⑤건축물의 정비·개량 및 건축시설계획	〃	
			⑥도시경관·환경보전·재난방지 계획	〃	
			⑦구역주변의 교육환경 보호계획	〃	
			⑧기존수목의 현황 및 활용계획	〃	
			⑨안전·범죄예방 사항	〃	
			⑩재원조달방안	〃	
			⑪환경성검토	〃	
			⑫교통성검토	〃	
		4.성과품작성	①보고서작성 및 편집	〃	
			②관련도서작성	〃	
		5.주민워크샵	①주민워크삽 등	〃	
		6.기술협의	①공청회 / 주민설명회	〃	
			②주민간담회 / 시민계획단	〃	
			③위원회심의 지원	〃	
			④관계기관 협의	〃	
	직접경비	여비, 인쇄비, 조감도, 회의준비비, 현장운영비 등		식	제1장 총칙참조
간접비	제경비	(직접인건비)×120%		〃	〃
	기술료	(직접인건비+제경비)×30%		〃	〃

4) 구역해제 및 관리방안

종 별		내 용	세부항목	단 위	비 고
직접비	직접인건비	1.현황조사	①주민·산업의 현황 ②토지·건축물의 이용·소유현황 ③정비기반시설의 설치현황 ④정비구역·주변지역의 교통상황 ⑤토지·건축물의 가격·임대차 현황 ⑥개략 사업성 분석 ⑦정비사업에 대한 주민의 의견	인·일 〃 〃 〃 〃 〃 〃	
		2.구역 해제에 따른 문제점 분석	①토지이용계획 ②기반시설 및 공공용지 분담계획 ③교통처리 계획	〃 〃 〃	
		3.구역해제에 따른 대책 검토	①상위계획, 주변지역 계획과 정합성 유지방안 ②정비기반시설의 조정방안 ③기존 건축물의 정비·개량 계획 ④환경보전·재난방지 계획 ⑤대책 반영에 따른 소요비용 비교 검토 ⑥공공 지원 대책 검토 ⑦관계법령에 따른 후속 추진사항 검토	〃 〃 〃 〃 〃 〃 〃	
		4.성과품작성	①보고서작성 및 편집 ②관련도서작성	〃 〃	
		5.기술협의	①공청회 / 주민설명회 ②주민간담회 / 시민계획단 ③위원회심의 지원 ④관계기관 협의	〃 〃 〃 〃	
	직접경비	여비, 인쇄비, 자문비, 조감도, 회의준비비, 설문조사비, 현장운영비 등		식	제1장 총칙 참조
간접비	제 경 비	(직접인건비)×120%		〃	〃
	기 술 료	(직접인건비+제경비)×30%		〃	〃

3. 가로주택정비사업(사업계획)

종 별		내 용	세부항목	단 위	비 고
직접비	직접인건비	1.현황조사	①가로주택정비사업 충족여부 ②도시·군관리계획현황 ③토지현황 ④건축물현황 ⑤공시가격	인·일 〃 〃 〃 〃	
		2.사업계획	①주택건설예정 호수·세대수 ②시행구역 및 범위·지번·지목 및 등기명의자 ③도시·군관리계획의 용도지역 ④대지·주변현황 사업계획서 ⑤위치도 및 현황도 ⑥토지·건축물 지적현황도	〃 〃 〃 〃 〃 〃	
		3.성과품작성	①보고서작성 및 편집 ②관련도서작성	〃 〃	
		4.기술협의	①공청회 / 주민설명회 ②주민간담회 / 시민계획단 ③위원회심의 지원 ④관계기관 협의	〃 〃 〃 〃	
	직접경비	여비, 인쇄비, 조감도, 회의준비비, 현장운영비 등		식	제1장 총칙참조
간접비	제경비	(직접인건비)×120%		〃	〃
	기술료	(직접인건비+제경비)×20%		〃	〃

4. 사업시행계획

종 별		내 용	세부항목	단 위	비 고
직접비	직접인건비	1.토지 및 건물권리조사	①지적도 복사, 토지 및 건물대장 및 등기부 열람 ②고정자산세, 과세표준액 등 조사	인·일 〃	
		2.기본설계	-	식	
		3.자금계획	①개략사업비 산정 ②수지계획	인·일 〃	
		4.사업시행계획	①설계설명서 ②부속도서 ③인가신청서	〃 〃 〃	
		5.실시설계	-	식	
		6.성과품작성	①보고서작성 및 편집 ②관련도서작성	인·일 〃	
		7.기술협의	①공청회 / 주민설명회 ②주민간담회 / 시민계획단 ③위원회심의 지원 ④관계기관 협의	〃 〃 〃 〃	
	직접경비	여비, 인쇄비, 조감도, 회의준비비, 현장운영비 등		식	제1장 총칙참조
간접비	제경비	(직접인건비)×120%		〃	〃
	기술료	(직접인건비+제경비)×30%		〃	〃

5. 관리처분계획

종 별		내 용	세부항목	단 위	비 고
직접비	직접인건비	1.분양설계기준	①토지 및 건물 권리조사 보정 ②종전 토지지적의 결정 ③토지 및 건물가격 평가기준 작성 ④분양설계기준의 작성	인·일 〃 〃 〃	
		2.토지평가	①자료조사 ②정리전후 노선가 설정 ③정리전 각 필지평가 ④정리후 가구평가 ⑤증진율 계산	〃 〃 〃 〃 〃	
		3-1.비례평가식 환지(분양) 계산	①비례율 산정 ②권리지수 산정 ③분양배당지수 및 지적산출	〃 〃 〃	
		3-2.절충식 환지 (분양) 계산	①공통부담률 계산 ②잠정환지 지적 ③잠정환지의 평가 ④증가배분율의 계산 ⑤권리지수 산정	〃 〃 〃 〃 〃	
		3-3.면적식 환지 (분양) 계산	①공통부담률 계산 ②급지별 공통부담률 계산	〃 〃	
		4.환지(분양) 할당설계	①가할당 ②분양할당 ③분양할당 수정 ④가구별 분양조서 및 할당도 ⑤공람에 따른 분양계산의 보완 ⑥분양원가 설명	〃 〃 〃 〃 〃 〃	
		5.환지(분양) 예정지지정	①분양예정지 지정서 작성	식	
		6.분양설계서	①인가 신청도서 작성	인·일	
		7.성과품작성	①보고서작성 및 편집 ②관련도서작성	〃 〃	
		8.기술협의	①공청회 / 주민설명회 ②주민간담회 / 시민계획단 ③위원회심의 지원 ④관계기관 협의	〃 〃 〃 〃	
	직접경비	여비, 인쇄비, 조감도, 회의준비비, 현장운영비 등		식	제1장 총칙참조
간접비	제경비	(직접인건비)×120%		〃	〃
	기술료	(직접인건비+제경비)×30%		〃	〃

3-4-2 산정기준

1. 계획·기준면적의 설정

○ 사업의 조사설계산정의 원단위 책정을 마련하기 위하여 기준면적을 다음과 같이 설정한다.

구 분	도시·주거환경정비 기본계획	구역지정 (정비계획)	가로주택정비사업 (사업계획)	사업시행계획	관리처분계획
기준면적	50만㎡	5만㎡	1만㎡	5만㎡	5만㎡

○ 계획면적은 과정별 업무성격에 따라 과업지구면적을 기준으로 산정한다.

2. 표준품의 산정방법

○ 표준품의 적용에 있어 기준면적과 계획면적의 차이에 따른 품 산정은 아래의 수정식에 따라 기준면적의 소요작업량을 수정하여 산정한다.

○ 소요작업량 = 기준면적소요작업량×면적보정계수($\alpha, \beta, \gamma, \delta$)×계획별보정계수($\pi, \phi, \zeta$)

○ 업무에 필요한 자료는 자료제공의 전제에 따라 발주자의 제공이 불가능하여 엔지니어링사업자에게 작성토록 할 경우 그의 내용에 따라 실비로 계상한다.

○ 업무의 수행에 필요한 각종 평가업무(교통, 환경, 재해, 경관)은 제8장 도시평가의 해당품을 별도 적용하며, 측량·전산처리·시험 등의 경비에 대하여는 실비로 가산한다.

○ 지구단위의 사업시행인가(고시)용 계획 및 건축배치계획을 중심으로 보다 상세한 계획이 요구될 때에는 업무의 범위로 보아 그 소요되는 작업량의 산정은 토목설계의 경우 제5장 제3절 주택단지 개발계획에 준하며, 건축설계의 경우는 제4장 제1절 지구단위계획의 건축물에 관한 계획의 품을 준용한다.

○ 도시·주거환경정비기본계획의 기초조사는 도시・군기본계획의 해당품을 적용한다.

3. 계획안의 수정과 과업중지에 따른 품 산정방법

○ 계획안이 작성되고 주민공람, 의회보고 등 행정절차과정을 거쳐 계획안이 확정된 후 발주자의 사정에 의하여 계획안이 일부변경 · 재작업이 수행되는 경우에는 그 변경·재작업의 정도에 따라 엔지니어링사업대가의 50～100% 수준에서 비용을 추가 지급하여야 한다.

○ 과업수행 중 발주자의 사정에 따른 과업 중단으로 인해 정부 회계연도가 경과되어 현저한 비용의 차이가 발생하였을 경우에는 엔지니어링사업대가를 당해 신년도의 노임단가를 기준으로 재산정하여야 한다.

3-4-3 단위별 변화수정과 보정

1. 작업량 보정계수 산정

1) 면적의 대소에 대한 작업량 보정계수 산정

○ 도시· 주거환경정비기본계획 면적이 기준면적을 초과하거나 못 미치는 경우의 직접인력 소요작업량의 산정을 위한 보정계수(α)는 다음과 같이 산정한다.

(1) 도시· 주거환경정비 기본계획

$$\alpha = (\frac{\text{계획면적}}{\text{기준면적}})^{0.6} = (\frac{A}{50})^{0.6}$$

α = 보정계수
A = 계획면적(만㎡)

○ 기준면적(50만㎡)이하는 50만㎡에 준한다.

(2) 구역지정(정비계획) : 주택재개발사업· 주택재건축사업· 도시환경정비사업· 주거환경개선사업· 주거환경관리사업· 구역해제 및 관리방안

$$\beta = (\frac{\text{계획면적}}{\text{기준면적}})^{0.7} = (\frac{A}{5})^{0.7}$$

β = 보정계수
A = 계획면적(만㎡)

○ 기준면적(5만㎡)이하는 3만㎡에 준한다.

(3) 가로주택정비사업(사업계획)

$$\gamma = (\frac{\text{계획면적}}{\text{기준면적}}) = (\frac{A}{1})$$

ϒ = 보정계수
A = 계획면적(만㎡)

○ 기준면적(1만㎡)이하는 1만㎡에 준한다.

(4) 사업시행계획

$$\delta = (0.2 \times \text{계획면적}) = 0.2A$$

δ = 보정계수
A = 계획면적(만㎡)

○ 기준면적(5만㎡)이하는 3만㎡에 준한다.

(5) 관리처분계획

$$\epsilon = (0.2 \times \text{계획면적}) = 0.2A$$

ε = 보정계수
A = 계획면적(만㎡)

○ 기준면적(5만㎡)이하는 3만㎡에 준한다.

계획면적에 대한 작업량 보정계수

면적(A) 만㎡	보정계수						
	도시·주거환경 정비기본계획 (α)	구역지정 (정비계획) (β)	사업시행 계획 (δ)	관리처분 계획 (ε)	계획종류 (π)	지구밀도의 변화 (φ)	인구밀도의 변화 (ζ)
3.0	1.000	0.699	0.600	0.600			
5.0	1.000	1.000	1.000	1.000			
10.0	1.000	1.625	2.000	2.000			
15.0	1.000	2.158	3.000	3.000			
20.0	1.000	2.639	4.000	4.000			
25.0	1.000	3.085	5.000	5.000			
30.0	1.000	3.505	6.000	6.000			
40.0	1.000	4.287	8.000	8.000	1.0		
50.0	1.000	5.012	10.000	10.000		0.5+ 0.0025K	0.55+ 0.003P
60.0	1.116	5.694	12.000	12.000	/		
70.0	1.224	6.343	14.000	14.000			
75.0	1.275	6.657	15.000	15.000	1.5		
80.0	1.326	6.964	16.000	16.000			
90.0	1.423	7.563	18.000	18.000			
100.0	1.516	8.142	20.000	20.000			
150.0	1.933	10.814	30.000	30.000			
200.0	2.297	13.226	40.000	40.000			
300.0	2.930	17.567	60.000	60.000			
400.0	3.482	21.486	80.000	80.000			

주 : ① 가로주택정비사업(사업계획)의 경우 1만㎡를 최소기준으로 하여 산정한다.

2) 정비사업 종류에 대한 작업량 보정계수 산정

○ 정비사업인 주택재개발사업과 도시환경정비사업은 계획의 성격상 업무내용과 범위에서 큰 차이를 보이므로 정비계획, 사업시행계획, 관리처분계획에 대하여는 작업량 보정 계수를 다음과 같이 설정하여 적용한다.

구 분		보정계수(π)
주택재개발사업·주택재건축사업 주거환경관리사업·주거환경개선사업·가로주택정비사업		1.0
도시환경정비사업	전면개발	1.0
	수복개발	1.5

3) 지구밀도의 변화에 따른 수정

$\phi = (0.5+0.0025K)$

ϕ = 보정계수
K = 지구내 총필지수

K	1,000	900	800	700	600	500	400	300	200	100
ϕ	3.00	2.75	2.50	2.25	2.00	1.75	1.50	1.25	1.00	0.75

4) 인구밀도의 변화에 따른 수정

$\zeta = (0.55+0.003P)$

ζ = 보정계수
P = 인구밀도(인 / ha)

P	1,000	800	600	500	400	300	250	200	150	100
ζ	3.55	2.95	2.35	2.05	1.75	1.45	1.3	1.15	1	0.85

2. 직접인건비 소요 작업량 산정

○ 계획면적의 대소에 따른 직접인력 소요작업량의 산정방법은 아래와 같이 기준면적의 직능별 직접인력 소요작업량에 계획단위 보정계수(α, β, Υ, δ, ε, π, ϕ, ζ)을 곱하여 산출한다.

구 분	기준 면적 (만㎡)	총작업량(인·일)						
		기술사	특 급	고 급	중 급	초 급	보조원	비고
기본계획	50	51.7α	83.5α	213.3α	350.9α	520.1α	529.8α	
구역지정 (정비계획)	5	$20.2\beta\pi\zeta$	$40.5\beta\pi\zeta$	$106.1\beta\pi\zeta$	$211.8\beta\pi\zeta$	$288.4\beta\pi\zeta$	$300.1\beta\pi\zeta$	
		$14.2\beta1.2\zeta$	$22.8\beta1.2\zeta$	$56.1\beta1.2\zeta$	$103.3\beta1.2\zeta$	$131.7\beta1.2\zeta$	$140.4\beta1.2\zeta$	주거환경 개선사업
		$18.4\beta\pi\zeta$	$36.7\beta\pi\zeta$	$96.0\beta\pi\zeta$	$192.1\beta\pi\zeta$	$267.8\beta\pi\zeta$	$282.1\beta\pi\zeta$	주거환경 관리사업
		$14.1\beta\pi\zeta$	$27.3\beta\pi\zeta$	$70.0\beta\pi\zeta$	$149.9\beta\pi\zeta$	$200.8\beta\pi\zeta$	$212.9\beta\pi\zeta$	구역해제 및 관리방안
가로주택 정비사업 (사업계획)		$3.7\Upsilon\pi\zeta$	$8.3\Upsilon\pi\zeta$	$18.8\Upsilon\pi\zeta$	$37.4\Upsilon\pi\zeta$	$50.4\Upsilon\pi\zeta$	$52.8\Upsilon\pi\zeta$	
사업시행계획	5	$2.4\delta\pi$	$2.6\delta\pi$	$14.2\delta\pi$	$12.0\delta\pi$	$20.9\delta\pi$	$17.9\delta\pi$	
관리처분계획	5	$17.5\varepsilon\pi\phi$	$18.0\varepsilon\pi\phi$	$99.0\varepsilon\pi\phi$	$140.0\varepsilon\pi\phi$	$212.1\varepsilon\pi\phi$	$198.1\varepsilon\pi\phi$	평가식 기준

주 : ①기본계획의 소요작업은 현황조사를 제외한 작업량임
②기본계획에서는 작업량 보정계수(π)를 적용하지 않는다.
③평가식 환지기준 적용

3-5 표준단위 업무분류와 원단위

3-5-1 도시 · 주거환경정비 기본계획

기술업무의 직능별 직접인력 소요작업량(면적 50만㎡ 기준)

(단위 : 인·일/표준단위)

구 분	업무내용	표준단위	소요인력						비고
			기술사	특 급	고 급	중 급	초 급	보조원	
1.현황조사	①도시현황조사	50만㎡	11.8	18.9	79.3	119.7	198.8	214.5	
	②관련계획조사	50만㎡	1.3	2.1	2.8	7.8	7.8	10.5	
	③교통관계조사	50만㎡	1.5	2.3	5.2	10.5	10.2	10.5	
	④시설관계조사	50만㎡	1.5	2.3	7.8	10.7	13.1	13.3	
	⑤공급처리시설 관계조사	50만㎡	1.3	2.1	5.5	7.8	8.4	7.8	
	소 계		17.4	27.7	100.6	156.5	238.3	256.6	
2.기본계획	①기본원칙	50만㎡	1.8	2.9	5.8	9.6	14.4	9.2	
	②정비예정구역의 설정	50만㎡	1.3	2.1	3.9	6.6	9.7	9.2	
	③도심기능의 활성화 및 도심 공동화 방지 방안	50만㎡	1.3	2.1	3.9	6.6	9.7	9.2	
	④주거지 관리계획	50만㎡	1.5	2.5	4.9	8.1	11.9	11.5	
	⑤공공과 민간의 역할 분담계획	50만㎡	1.3	2.1	3.9	6.6	9.7	9.2	
	⑥재원조달계획	50만㎡	1.3	2.1	3.9	6.6	9.7	9.2	
	⑦단계별 추진계획	50만㎡	1.3	2.1	3.9	6.6	9.7	9.2	
	⑧사업지구내 거주민 주거안정대책	50만㎡	1.5	2.5	4.9	8.1	11.9	11.5	
	⑨정비예정구역의 관리계획	50만㎡	1.5	2.5	4.9	8.1	11.9	11.5	
	⑩토지이용계획	50만㎡	1.8	2.9	5.8	9.7	14.4	13.8	
	⑪정비기반시설계획 및 공동이용시설 설치계획	50만㎡	1.5	2.4	4.9	8.1	12.0	11.5	
	⑫교통계획	50만㎡	1.8	2.9	5.8	9.7	14.4	13.8	
	⑬환경계획	50만㎡	1.8	2.9	5.8	9.7	14.4	18.4	
	⑭사회복지 및 주민문화시설 등의 설치계획	50만㎡	1.5	2.4	4.9	8.1	11.9	11.5	
	⑮건폐율·용적률 등에 관한 건축물의 밀도계획	50만㎡	1.8	2.9	5.8	9.7	14.4	13.8	
	⑯역사적 유물 및 전통건축물 보존 및 활용계획	50만㎡	1.3	2.1	3.9	6.6	9.7	9.2	
	⑰도시경관에 관한 계획	50만㎡	1.2	2.1	3.9	6.6	9.7	9.2	
	소 계		25.5	41.5	80.8	135.1	199.5	190.9	
3.성과품작성	①보고서작성 및 편집	50만㎡	6.0	9.4	21.2	35.4	35.1	23.3	
	②관련도서작성	50만㎡	2.8	4.9	10.7	23.9	47.2	59.0	
	소 계		8.8	14.3	31.9	59.3	82.3	82.3	
총 계			51.7	83.5	213.3	350.9	520.1	529.8	
4.기술협의	①공청회/주민설명회	1식	2.0	2.0	2.0	4.0	4.0	4.0	주1
	②주민간담회/시민계획단	1식	2.0	2.0	2.0	4.0	4.0	4.0	
	③위원회심의 지원	1식	2.0	2.0	2.0	4.0	4.0	4.0	
	④관계기관 협의	1식	2.0	2.0	2.0	4.0	4.0	4.0	
	소 계		8.0	8.0	8.0	16.0	16.0	16.0	

주 : ①기술협의는 2회 이내 기준이며, 횟수가 늘어날 경우 증가배수에 해당하는 작업품과 비용을 가산한다. (필요항목 선택적 적용)

②각종영향성검토 및 각종영향평가업무는 별도의 엔지니어링활동업무로 계상한다.

3-5-2 구역지정(정비계획)

1) 주택재개발사업·주택재건축사업·도시환경정비사업

기술업무의 직능별 직접인력 소요작업량(면적 5만㎡ 기준)

(단위 : 인·일/표준단위)

구 분	업무내용	표준단위	소요인력						비고
			기술사	특 급	고 급	중 급	초 급	보조원	
1.현황조사	①주민·산업의 현황	5만㎡	0.5	1.0	2.5	6.3	10.3	10.2	
	②토지·건축물의 이용·소유현황	5만㎡	2.0	4.0	8.9	24.2	27.7	33.0	
	③정비기반시설의 설치현황	5만㎡	0.5	1.0	1.3	4.0	5.2	9.0	
	④정비구역·주변지역의 교통상황	5만㎡	0.5	1.0	2.6	7.5	10.0	12.8	
	⑤토지·건축물의 가격·임대차 현황	5만㎡	0.5	1.0	2.5	6.3	10.3	10.2	
	⑥정비사업에 대한 주민의 의견	5만㎡	0.0	0.0	2.4	7.9	10.0	12.8	
	소 계		4.0	8.0	20.2	56.2	73.5	88.0	
2.정비계획	①계획의 수립방향	5만㎡	0.3	0.5	1.6	3.0	3.8	3.6	
	②정비사업의 시행 계획	5만㎡	0.3	0.5	1.6	3.0	3.8	3.6	
	③토지이용계획	5만㎡	2.3	4.6	11.4	22.9	34.5	34.4	
	④정비기반시설의 설치 계획	5만㎡	2.3	4.6	11.4	22.9	34.5	34.4	
	⑤공동이용시설 설치계획	5만㎡	1.1	2.3	8.6	14.2	17.1	17.0	
	⑥기존 건축물의 정비·개량 계획	5만㎡	0.3	0.6	2.0	3.0	3.8	3.6	
	⑦건축물 계획	5만㎡	2.9	5.7	14.3	24.9	34.4	33.5	
	⑧교통·동선처리계획	5만㎡	1.7	3.3	8.6	14.2	17.1	17.0	
	⑨환경보전·재난방지 계획	5만㎡	0.3	0.5	1.6	3.0	3.8	3.6	
	⑩구역 주변의 교육환경 보호 계획	5만㎡	0.2	0.5	1.6	3.0	3.8	3.6	
	⑪구역의 분할·결합에 관한 계획	5만㎡	0.2	0.5	1.6	3.0	3.8	3.6	
	⑫주택수급에 관한 사항	5만㎡	0.2	0.5	1.6	2.5	3.7	3.6	
	⑬세입자 주거대책	5만㎡	0.2	0.5	1.6	2.5	3.7	3.6	
	⑭안전·범죄예방 사항	5만㎡	0.2	0.5	1.6	2.5	3.7	3.6	
	소 계		12.5	25.1	69.1	124.6	171.5	168.7	
3.성과품작성	①보고서작성 및 편집	5만㎡	2.5	4.9	11.2	18.6	18.7	12.5	
	②관련도서작성	5만㎡	1.2	2.5	5.6	12.4	24.7	30.9	
	소 계		3.7	7.4	16.8	31.0	43.4	43.4	
총 계			20.2	40.5	106.1	211.8	288.4	300.1	
4.기술협의	①공청회/주민설명회	1식	2.0	2.0	2.0	4.0	4.0	4.0	주1
	②주민간담회/시민계획단	1식	2.0	2.0	2.0	4.0	4.0	4.0	
	③위원회심의 지원	1식	2.0	2.0	2.0	4.0	4.0	4.0	
	④관계기관 협의	1식	2.0	2.0	2.0	4.0	4.0	4.0	
	소 계		8.0	8.0	8.0	16.0	16.0	16.0	

주 : ①기술협의는 2회 이내 기준이며, 횟수가 늘어날 경우 증가배수에 해당하는 작업품과 비용을 가산한다. (필요항목 선택적 적용)

②환경성검토는 환경영향평가의 내용을 반영하기 위한 작업만을 범위로 한다.

2) 주거환경개선사업

기술업무의 직능별 직접인력 소요작업량(면적 5만㎡ 기준)

(단위 : 인·일/표준단위)

구 분	업무내용	표준단위	소요인력						비고
			기술사	특 급	고 급	중 급	초 급	보조원	
1.현황조사	①토지이용현황조사	5만㎡	0.7	1.0	2.7	6.7	8.1	9.5	
	②건물현황조사	5만㎡	0.6	0.9	2.6	6.8	8.1	9.4	
	③인구 및 산업현황조사	5만㎡	0.4	0.6	1.3	3.4	5.4	5.4	
	④도시시설설치현황조사	5만㎡	0.4	0.6	0.7	2.0	2.7	4.8	
	⑤교통관계조사	5만㎡	0.4	0.6	1.4	4.0	5.4	6.8	
	⑥공급처리시설 관계조사	5만㎡	0.3	0.6	0.7	2.8	4.0	4.1	
	⑦주민생활형편조사	5만㎡	-	-	1.3	4.1	5.3	6.7	
	소 계		2.8	4.3	10.7	29.8	39.0	46.7	
2.기본구상	①기초조사·분석	5만㎡	0.5	0.9	1.3	2.2	2.2	3.4	
	②개발정비조건 및 내용설정	5만㎡	0.5	0.9	1.6	2.2	2.2	3.4	
	③구상안 작성	5만㎡	1.3	2.0	4.0	4.0	4.5	4.5	
	④기술적 타당성 검토	5만㎡	0.7	1.0	1.8	2.6	2.6	2.6	
	⑤경제적 타당성 검토	5만㎡	0.5	0.8	1.4	2.0	2.0	2.0	
	소 계		3.5	5.6	10.1	13.0	13.5	15.9	
3.기본계획	①토지이용계획	5만㎡	1.5	2.4	6.1	12.1	18.2	18.2	
	②공공시설정비계획	5만㎡	0.8	1.2	4.6	6.1	9.1	9.1	
	③주택의 건설 및 부대, 복리시설계획	5만㎡	1.8	2.9	5.8	9.5	13.6	13.4	
	④건축물의 개량	5만㎡	0.9	1.6	3.8	6.6	9.1	8.9	
	⑤관리운영계획	5만㎡	0.7	1.2	4.0	7.6	9.1	8.6	
	⑥기타계획	5만㎡	0.7	1.2	4.0	7.6	9.1	8.6	
	소 계		6.4	10.5	28.3	49.5	68.2	66.8	
4.성과품 작성	①보고서작성 및 편집	5만㎡	1.0	1.6	4.0	6.0	5.0	4.0	
	②관련도서작성	5만㎡	0.5	0.8	3.0	5.0	6.0	7.0	
	소 계		1.5	2.4	7.0	11.0	11.0	11.0	
총 계			14.2	22.8	56.1	103.3	131.7	140.4	
5.기술협의	①공청회/주민설명회	1식	2.0	2.0	2.0	4.0	4.0	4.0	주1
	②주민간담회/시민계획단	1식	2.0	2.0	2.0	4.0	4.0	4.0	
	③위원회심의 지원	1식	2.0	2.0	2.0	4.0	4.0	4.0	
	④관계기관 협의	1식	2.0	2.0	2.0	4.0	4.0	4.0	
	소 계		8.0	8.0	8.0	16.0	16.0	16.0	

주 : ①기술협의는 2회 이내 기준이며, 횟수가 늘어날 경우 증가배수에 해당하는 작업품과 비용을 가산한다. (필요항목 선택적 적용)
②환경성검토는 환경영향평가의 내용을 반영하기 위한 작업만을 범위로 한다.

3) 주거환경관리사업

기술업무의 직능별 직접인력 소요작업량(면적 5만㎡ 기준)

(단위 : 인·일/표준단위)

구 분	업무내용	표준단위	소요인력						비고
			기술사	특 급	고 급	중 급	초 급	보조원	
1.현황조사	①도시계획현황 및 지형현황	5만㎡	0.2	0.4	1.3	4.1	5.5	6.6	
	②토지이용현황	5만㎡	0.5	1.0	4.5	11.4	15.2	17.8	
	③건축물현황	5만㎡	0.5	1.1	4.6	11.4	15.2	17.8	
	④인구 및 산업현황	5만㎡	0.5	1.0	2.5	6.3	10.3	10.2	
	⑤정비사업에 대한 주민의 의견	5만㎡	0.1	0.4	1.2	4.1	5.6	6.8	
	⑥가로시설물 및 조경환경	5만㎡	0.2	0.4	1.3	4.1	5.5	6.6	
	⑦자연환경 및 생활환경	5만㎡	0.2	0.4	1.3	4.1	5.5	6.6	
	⑧교통관련현황	5만㎡	0.2	0.4	1.3	4.1	5.5	6.6	
	⑨도시시설 설치현황	5만㎡	0.5	1.0	1.3	4.0	5.2	9.0	
	소 계		2.9	6.1	19.3	53.6	73.5	88.0	
2.기본구상	①정비목표 및 구현전략의 설정	5만㎡	0.7	1.3	1.7	2.5	2.7	3.6	
	②기본방향 및 지표설정	5만㎡	0.8	1.4	1.9	2.7	3.3	4.4	
	소 계		1.5	2.7	3.6	5.2	6.0	8.0	
3.부문별계획	①토지이용계획	5만㎡	0.4	1.1	3.4	7.3	8.6	7.4	
	②공동이용시설 설치계획	5만㎡	0.3	1.1	3.4	7.3	8.6	7.4	
	③주민공동체 활성화 방안	5만㎡	6.9	9.9	22.7	30.9	60.1	68.7	
	④주거환경관리사업 시행계획	5만㎡	0.3	1.1	3.4	7.3	8.6	7.4	
	⑤건축물의 정비·개량 및 건축시설계획	5만㎡	0.3	1.1	3.4	7.3	8.6	7.4	
	⑥도시경관·환경보전·재난방지 계획	5만㎡	0.3	1.1	3.4	7.3	8.6	7.4	
	⑦구역주변의 교육환경 보호계획	5만㎡	0.3	1.1	3.4	7.3	8.6	7.4	
	⑧기존수목의 현황 및 활용계획	5만㎡	0.3	0.8	3.2	7.0	8.4	7.6	
	⑨안전·범죄예방 사항	5만㎡	0.3	1.1	3.4	7.3	8.6	7.4	
	⑩재원조달방안	5만㎡	0.3	1.1	3.4	7.3	8.6	7.4	
	⑪환경성검토	5만㎡	0.3	0.5	1.6	3.0	3.8	3.6	주1
	⑫교통성검토	5만㎡	0.3	0.5	1.6	3.0	3.8	3.6	
	소 계		10.3	20.5	56.3	102.3	144.9	142.7	
4.성과품작성	①보고서작성 및 편집	5만㎡	2.5	4.9	11.2	18.6	18.7	12.5	
	②관련도서작성	5만㎡	1.2	2.5	5.6	12.4	24.7	30.9	
	소 계		3.7	7.4	16.8	31.0	43.4	43.4	
총 계			18.4	36.7	96.0	192.1	267.8	282.1	
5.주민워크샵	①주민워크샵 등	26회	26.0	26.0	26.0	52.0	52.0	52.0	주2
	소 계		26.0	26.0	26.0	52.0	52.0	52.0	
6.기술협의	①공청회/주민설명회	1식	2.0	2.0	2.0	4.0	4.0	4.0	
	②주민간담회/시민계획단	1식	2.0	2.0	2.0	4.0	4.0	4.0	주3
	③위원회심의 지원	1식	2.0	2.0	2.0	4.0	4.0	4.0	
	④관계기관 협의	1식	2.0	2.0	2.0	4.0	4.0	4.0	
	소 계		8.0	8.0	8.0	16.0	16.0	16.0	

주 : ①각종영향성검토 및 각종영향평가업무는 별도의 엔지니어링활동업무로 계상하며, 환경성검토, 교통성 검토는 검토결과의 내용을 반영하기 위한 작업만을 범위로 한다.

②주민워크샵은 26회 기준이며, 횟수가 늘어날 경우 증가배수에 해당하는 작업품과 비용을 가산한다.

③기술협의는 2회 이내 기준이며, 횟수가 늘어날 경우 증가배수에 해당하는 작업품과 비용을 가산한다. (필요항목 선택적 적용)

4) 구역해제 및 관리방안

기술업무의 직종별 직접인력에 의한 소요작업량(5만㎡)

(단위 : 인·일/표준단위)

구 분	업무내용	표준단위	소요인력						비고
			기술사	특급	고급	중급	초급	보조원	
1.현황조사	①주민·산업의 현황	5만㎡	0.5	1.0	2.5	6.3	10.3	10.2	
	②토지·건축물의 이용·소유현황	5만㎡	2.0	4.0	8.9	24.2	27.7	33.0	
	③정비기반시설의 설치현황	5만㎡	0.5	1.0	1.3	4.0	5.2	9.0	
	④정비구역·주변지역의 교통상황	5만㎡	0.5	1.0	2.6	7.5	10.0	12.8	
	⑤토지·건축물의 가격·임대차 현황	5만㎡	0.5	1.0	2.5	6.3	10.3	10.2	
	⑥개략 사업성 분석	5만㎡	0.5	0.8	1.4	2.0	2.0	2.0	
	⑦정비사업에 대한 주민의 의견	5만㎡	0.0	0.0	2.4	7.9	10.0	12.8	
	소 계		4.5	8.8	21.6	58.2	75.5	90.0	
2.구역해제에 따른 문제점분석	①토지이용계획	5만㎡	0.2	0.5	1.1	2.3	3.5	3.4	
	②기반시설 및 공공용지 분담계획	5만㎡	0.2	0.5	1.1	2.3	3.5	3.4	
	③교통처리 계획	5만㎡	0.2	0.3	0.8	1.4	1.7	1.7	
	소 계		0.6	1.3	3.0	6.0	8.7	8.5	
3.구역해제에 따른 대책검토	①상위·주변지역 계획과 정합성 유지방안	5만㎡	0.3	0.5	1.6	3.0	3.8	3.6	
	②정비기반시설의 조정방안	5만㎡	2.3	4.6	11.4	22.9	34.5	34.4	
	③기존 건축물의 정비·개량 계획	5만㎡	0.3	0.6	2.0	3.0	3.8	3.6	
	④환경보전·재난방지 계획	5만㎡	0.3	0.5	1.6	3.0	3.8	3.6	
	⑤대책 반영에 따른 소요비용 비교 검토	5만㎡	0.7	1.2	4.0	7.6	9.1	8.6	
	⑥공공 지원 대책 검토	5만㎡	0.7	1.2	4.0	7.6	9.1	8.6	
	⑦관계법령에 따른 후속 추진사항 검토	5만㎡	0.7	1.2	4.0	7.6	9.1	8.6	
	소 계		5.3	9.8	28.6	54.7	73.2	71.0	
4.성과품작성	①보고서 작성	5만㎡	2.5	4.9	11.2	18.6	18.7	12.5	
	②관련도서 작성	5만㎡	1.2	2.5	5.6	12.4	24.7	30.9	
	소 계		3.7	7.4	16.8	31.0	43.4	43.4	
총 계			14.1	27.3	70.0	149.9	200.8	212.9	
5.기술협의	①공청회/주민설명회	1식	2.0	2.0	2.0	4.0	4.0	4.0	주1
	②주민간담회/시민계획단	1식	2.0	2.0	2.0	4.0	4.0	4.0	
	③위원회심의 지원	1식	2.0	2.0	2.0	4.0	4.0	4.0	
	④관계기관 협의	1식	2.0	2.0	2.0	4.0	4.0	4.0	
	소 계		8.0	8.0	8.0	16.0	16.0	16.0	

주 : ①기술협의는 2회 이내 기준이며, 횟수가 늘어날 경우 증가배수에 해당하는 작업품과 비용을 가산한다. (필요항목 선택적 적용)

3-5-3 가로주택정비사업

기술업무의 직능별 직접인력 소요작업량(면적 1만㎡ 기준)

(단위 : 인·일/표준단위)

구 분	업무내용	표준단위	소요인력						비고
			기술사	특 급	고 급	중 급	초 급	보조원	
1.현황조사	①가로주택정비사업 충족여부	1만㎡	0.5	1.0	1.3	4.0	5.2	9.0	
	②도시·군관리계획현황	1만㎡	0.1	0.2	0.6	1.8	2.3	2.1	
	③토지현황	1만㎡	0.1	0.2	0.6	1.8	2.3	2.1	
	④건축물현황	1만㎡	0.1	0.2	0.6	1.8	2.3	2.1	
	⑤공시가격	1만㎡	0.1	0.2	0.6	1.8	2.3	2.1	
	소 계		0.9	1.8	3.7	11.2	14.4	17.4	
2.사업계획	①주택건설예정 호수·세대수	1만㎡	0.6	1.1	2.8	5.0	6.9	6.7	
	②시행구역 및 범위·지번·지목 및 등기명의자	1만㎡	0.3	0.8	2.2	4.0	5.5	5.4	
	③도시·군관리계획의 용도지역	1만㎡	0.3	0.8	2.2	4.0	5.5	5.4	
	④대지·주변현황 사업계획서	1만㎡	0.3	0.8	2.2	4.0	5.5	5.4	
	⑤위치도 및 현황도	1만㎡	0.3	0.8	1.2	1.5	2.0	1.9	
	⑥토지·건축물 지적현황도	1만㎡	0.3	0.8	1.2	1.5	2.0	1.9	
	소 계		2.1	5.1	11.8	20.0	27.4	26.7	
3.성과품작성	①보고서작성 및 편집	1만㎡	0.5	0.9	2.2	3.7	3.7	2.5	
	②관련도서작성	1만㎡	0.2	0.5	1.1	2.5	4.9	6.2	
	소 계		0.7	1.4	3.3	6.2	8.6	8.7	
총 계			3.7	8.3	18.8	37.4	50.4	52.8	
4.기술협의	①공청회/주민설명회	1식	2.0	2.0	2.0	4.0	4.0	4.0	주1
	②주민간담회/시민계획단	1식	2.0	2.0	2.0	4.0	4.0	4.0	
	③위원회심의 지원	1식	2.0	2.0	2.0	4.0	4.0	4.0	
	④관계기관 협의	1식	2.0	2.0	2.0	4.0	4.0	4.0	
	소 계		8.0	8.0	8.0	16.0	16.0	16.0	

주 : ①기술협의는 2회 이내 기준이며, 횟수가 늘어날 경우 증가배수에 해당하는 작업품과 비용을 가산한다. (필요항목 선택적 적용)

3-5-4 사업시행계획

기술업무의 직능별 직접인력 소요작업량(면적 5만㎡, 필지 200 기준)

(단위 : 인·일/표준단위)

구 분	업무내용	표준단위	소요인력						비고
			기술사	특 급	고 급	중 급	초 급	보조원	
1.토지 및 건물권리 조사	①지적도 복사, 토지 및 건물 대상 및 등기부 열람	5만㎡외	0.7	0.8	4.3	5.4	10.3	11.1	주1
	②고정자산세, 과세표준액 등 조사	5만㎡외	-	-	1.3	0.9	1.9	1.9	
	소 계		0.7	0.8	5.6	6.3	12.2	13.0	
2.기본설계	엔지니어링 사업대가의 기준 중 건설부문 공사비 요율을 적용한다.								
3.자금계획	①개략사업비 산정	5만㎡외	0.7	0.8	3.8	-	-	-	
	②수지계획	5만㎡외	0.4	0.4	1.9	-	-	-	
	소 계		1.1	1.2	5.7	-	-	-	
4.사업시행 계획	①사업설명서	5만㎡외	0.2	0.2	0.8	1.9	3.4	-	
	②부속도서	5만㎡외	0.2	0.2	1.7	2.3	4.5	4.5	
	③인가신청	5만㎡외	0.2	0.2	0.4	1.5	0.8	0.4	
	소 계		0.6	0.6	2.9	5.7	8.7	4.9	
5.실시설계	엔지니어링 사업대가의 기준 중 건설부문 공사비 요율을 적용한다.								
총 계			2.4	2.6	14.2	12.0	20.9	17.9	
6.기술협의	①공청회/주민설명회	1식	2.0	2.0	2.0	4.0	4.0	4.0	주2
	②주민간담회/시민계획단	1식	2.0	2.0	2.0	4.0	4.0	4.0	
	③위원회심의 지원	1식	2.0	2.0	2.0	4.0	4.0	4.0	
	④관계기관 협의	1식	2.0	2.0	2.0	4.0	4.0	4.0	
	소 계		8.0	8.0	8.0	16.0	16.0	16.0	

주 : ①필지 200기준은 최소기준이며 증가필지수에 비례하여 1.토지 및 건물권리조사 항목의 작업품 및 비용이 가산됨.

②기술협의는 2회 이내 기준이며, 횟수가 늘어날 경우 증가배수에 해당하는 작업품과 비용을 가산한다. (필요항목 선택적 적용)

3-5-5 관리처분계획

기술업무의 직능별 직접인력 소요작업량(면적 5만㎡, 필지 200 기준)

(단위 : 인·일/표준단위)

구 분	업무내용	표준단위	소요인력						비고
			기술사	특 급	고 급	중 급	초 급	보조원	
1.분양설계기준	①토지 및 건물 권리조사 보정	5만㎡외	-	-	3.4	8.6	13.7	-	주1
	②종전토지지적의 결정	5만㎡외	0.3	0.3	4.9	8.1	20.1	18.4	
	③토지 및 건물가격 평가기준 작성	5만㎡외	1.5	1.5	5.6	5.1	2.1	2.1	
	④분양설계기준의 작성	5만㎡외	1.9	1.9	5.6	4.3	3.0	1.3	
	소 계		3.7	3.7	19.5	26.1	38.9	21.8	
2.토지평가	①자료조사	5만㎡외	0.2	0.2	1.3	0.9	1.3	0.4	
	②정리전후 노선가 설정	5만㎡외	1.5	1.5	9.0	9.4	9.8	9.4	
	③정리전 각 필지 평가	5만㎡외	-	-	3.4	8.6	17.1	18.0	
	④정리후 가구평가	5만㎡외	0.4	0.5	1.7	6.0	10.7	8.6	
	⑤증진율 계산	5만㎡외	0.4	0.5	1.7	1.7	0.9	0.9	
	소 계		2.5	2.7	17.1	26.6	39.8	37.3	
3-1.비례 평가식 환지 (분양)계산	①비례율 산정	5만㎡외	0.8	0.9	9.4	10.3	12.0	8.6	
	②권리지수 산정	5만㎡외	-	-	0.9	1.7	5.6	6.4	
	③분양배당지수 및 지적산출	5만㎡외	-	-	3.8	5.6	6.4	5.6	
	소 계		0.8	0.9	14.1	17.6	24.0	20.6	
3-2.절충식 환지 (분양)계산	①공통부담률 계산	5만㎡외	-	-	0.4	5.1	4.7	4.7	
	②잠정환지 지적	5만㎡외	-	-	-	7.7	8.6	8.6	
	③잠정환지의 평가	5만㎡외	-	-	-	3.4	3.4	6.0	
	④증가배분율의 계산	5만㎡외	-	-	0.9	0.4	3.0	3.4	
	⑤권리지수 산정	5만㎡외	-	-	-	3.0	3.0	2.6	
	소 계		-	-	1.3	19.6	22.7	25.3	
3-3.면적식 환지 (분양)계산	①공통부담률 계산	5만㎡외	-	-	0.4	5.1	4.7	4.7	
	②급지별 공통부담률 계산	5만㎡외	0.8	0.9	9.4	10.3	12.0	8.6	
	소 계		0.8	0.9	9.8	15.4	16.7	13.3	
4.환지 (분양)식 할당설계	①가할당※	5만㎡외	-	-	6.0	6.0	6.8	6.8	
	②분양할당	5만㎡외	4.0	4.0	15.0	18.0	21.8	16.2	
	③분양할당 수정	5만㎡외	0.2	0.2	2.1	4.7	5.1	6.4	
	④가구별 분양조서 및 할당도	5만㎡외	-	-	-	-	9.4	10.3	
	⑤공람에 따른 분양계산의 보완	5만㎡외	-	-	-	8.1	9.0	-	
	⑥분양원가 설명	5만㎡외	1.5	1.5	3.0	3.0	-	-	
	소 계		5.7	5.7	26.1	39.8	52.1	39.7	주2
			5.7	5.7	20.1	33.8	45.3	32.9	주3
5.환지(분양)예정지지정	①분양예정지 지정서 작성	5만㎡외	0.8	0.9	7.7	9.8	28.2	35.5	
6.분양설계서	①인가신청도서 작성	5만㎡외	4.0	4.1	14.5	20.1	29.1	43.2	
총 계			17.5	18.0	99.0	140.0	212.1	198.1	평가식
			16.7	17.1	80.2	136.0	204.0	196.0	절충식
			17.5	18.0	88.7	131.8	198.0	184.0	면적식
7.기술협의	①공청회/주민설명회	1식	2.0	2.0	2.0	4.0	4.0	4.0	주4
	②주민간담회/시민계획단	1식	2.0	2.0	2.0	4.0	4.0	4.0	
	③위원회심의 지원	1식	2.0	2.0	2.0	4.0	4.0	4.0	
	④관계기관 협의	1식	2.0	2.0	2.0	4.0	4.0	4.0	
	소 계		8.0	8.0	8.0	16.0	16.0	16.0	

주 : ①필지 200기준은 최소기준이며 증가 필지수에 비례하여 작업품 및 비용이 가산됨.
②평가식에 한함
③면적식 및 절충식
④기술협의는 2회 이내 기준이며, 횟수가 늘어날 경우 증가배수에 해당하는 작업품과 비용을 가산한다. (필요항목 선택적 적용)

3-6 주요업무내용

3-6-1 도시 및 주거환경정비 기본계획

구 분	업무내용	내 용
1.기초조사	①도시현황조사	·토지 및 건물조사 ·자연환경 및 토지이용상태조사 ·개발현황 활동인구조사
	②관련계획조사	·상위계획 및 관련계획 검토 ·시가지 변천조사 ·산업별 인구조사
	③교통관계조사	·주변교통현황조사 ·도로조사, 주차현황조사 ·교통시설조사 ·대중교통수단의 운용에 관한 조사
	④시설관계조사	·주요시설물조사 ·공원녹지 및 경관조사
	⑤공급처리시설 관계조사	·상·하수도 시설조사 ·전력통신시설조사, 에너지 수급현황조사
2. 기본계획	①기본원칙	·목표년도를 고려한 계획수립 ·기초조사와 기본계획 내용간 연계성 확보
	②정비예정구역의 설정	·지정기준 검토 ·정비사업 유형별 구역설정
	③도심기능의 활성화 및 도심공동화 방지 방안	·도심활성화 계획 ·공동화 방지 대책 수립
	④주거지관리계획	·주거지활성화 및 불량화 방지 대책 수립 ·물리적·비물리적 관리계획
	⑤공공과 민간의 역할분담 계획	·정기기반시설 설치 등 범위 설정 ·주민의 자발적 노력지원 방안검토
	⑥재원조달계획	·사업유형 및 정비예정구역별 방안 검토 ·시 예산, 제3섹터 방식 및 민간자본 등 조달계획
	⑦단계별 추진계획	·우선순위 선정 ·정비예정구역의 사업시기·기간 명시
	⑧사업지구내 거주민 주거안정 대책	·정비사업으로 인한 주거 영향 조사·분석 ·임대주택건설, 순환정비방식, 단계별 추진계획 등 ·재원확보 방안 제시
	⑨정비예정구역의 관리계획	·정비사업착수전 불량화 방지 대책수립 ·정비구역 지정후 건축물 규제범위 설정
	⑩토지이용계획	·토지이용 상황과 잠재력 반영 ·관련사업, 용도지역·지구를 고려한 계획수립
	⑪정비기반시설계획 및 공동이용시설 설치계획	·관련계획 및 시설기준을 고려한 계획 ·기반시설 부담의 형평성
	⑫교통계획	·교통체계 구상 ·주차장, 환승시설 등 교통시설 계획

구 분	업무내용	내 용
2. 기본계획 (계속)	⑬환경계획	·공원, 녹지 등 연계체계 구축 ·에너지 및 폐기물 처리계획 ·소음·진동 저감방안
	⑭사회복지 및 주민문화시설 등 설치계획	·설치 및 계획기준에 적합한 계획수립 ·주민의 특성을 고려한 시설의 배분 및 입지계획
	⑮건폐율·용적률 등에 관한 건축물의 밀도계획	·정비사업별, 정비예정 구역별 밀도계획 ·인센티브제도 및 건축물 높이 계획
	⑯역사적 유물 및 전통건축물 보존 및 활용계획	·유물 및 전통 건축물 조사 ·주변 문화재, 유물, 건축물의 종합 활용계획
	⑰도시경관에 관한 계획	·사업시행으로 인한 경관저해 대책 수립

3-6-2 구역지정(정비계획)

1) 주택재개발사업·주택재건축사업·도시환경정비사업

구 분	업무내용	내 용
1.현황조사	①주민·산업의 현황	·세대수 및 인구수 ·인구밀도, 호수밀도 ·거주가구 및 세입자 현황 ·정비구역안의 유·무형 문화유적, 보호수목현황 및 지역 유래
	②토지·건축물의 이용·소유현황	·토지의 이용 및 소유현황 ·토지의 지목별·규모별 현황 ·건축물의 이용 및 소유현황 ·건축물의 허가유무·노후불량 건축물현황 ·건축물의 용도, 구조, 규모 및 건축경과(준공)년도별 현황
	③정비기반시설의 설치현황	·도로, 공원, 녹지 ·도시·군관리계획상 토지이용계획 현황
	④정비구역·주변지역의 교통상황	·주변교통체계조사 ·주요 가로망·도로 조사
	⑤토지·건축물의 가격·임대차 현황	·임대료 및 지가조사 ·토지 및 건물가격의 변동 추이 ·주민생활형편 조사
	⑥정비사업에 대한 주민의 의견	·정비사업 시행계획 및 시행방법에 대한 주민(소유주)의견조사 ·토지 등 소유자의 정비구역지정에 관한 동의현황
2.정비계획	①계획의 수립방향	·계획의 배경 및 목적, 범위, 수립절차, 현황 ·계획지표 설정, 중점검토사항 및 계획요소 도출 ·계획의 기본구상
	②정비사업의 시행 계획	·정비사업의 명칭, 사업시행방법 ·정비사업시행 예정시기
	③토지이용계획	·토지이용계획 ·용도지역·지구 변경에 관한 계획

구 분	업무내용	내 용
2.정비계획 (계속)	④정비기반시설의 설치 계획	·도로, 주차장, 공원, 녹지 ·공공 · 문화체육시설 등 ·상·하수도, 전력·통신·가스
	⑤공동이용시설 설치계획	·관리사무소, 근린생활시설 및 소매시장, 상점 ·유치원, 경로당, 주민공동시설, 보육시설 ·문고 등 주택법 및 건축법에서 정한 시설별 건축물
	⑥기존 건축물의 정비·개량계획	·정비구역내 건축물의 철거·개량·보존 또는 존치 여부와 범위, 방향 ·역사적 유물과 전통적 건축물의 보존 및 정비와 계획
	⑦건축물 계획	·주택의 규모 및 건설비율 ·건축물의 주용도·건폐율·용적률·높이·층수·연면적에 관한 계획 ·건축선에 관한 계획
	⑧교통·동선처리계획	·정비계획에 따른 교통처리계획 ·가로망 체계구상 ·차도계획, 보행로계획 ·주차장 및 교통시설계획
	⑨환경보전·재난방지 계획	·지형 및 토양, 녹지 및 동식물상 ·일조, 에너지 등 ·화재, 수해, 지진, 유수지, 교통 등 ·홍수 등 재해에 대한 취약 요인에 관한 검토결과 포함
	⑩구역주변의 교육환경 보호계획	·학교시설 설치 및 교육환경 보호 ·정비사업 시행으로 인한 일조장애, 통학로 단절 등에 대한 대책
	⑪구역의 분할·결합에 관한 계획	·정비구역을 2개 이상의 구역으로 분할 ·2개 이상의 구역을 통합하여 지정
	⑫주택수급에 관한 사항	·각종 개발현황 및 주택공급계획을 조사 ·정비사업 시행으로 인한 주택수요 ·정비사업 시행으로 인해 주변지역의 전·월세난에 따른 정비사업시행 예정시기 조정
	⑬세입자 주거대책	·세입자에 대한 주거실태조사 ·임대주택건설, 인근의 임대주택 활용계획 ·주거이전비, 이사비 등 지급계획
	⑭안전·범죄예방 사항	·범죄 유발가능성이 있는 환경요소 ·청소년의 학습·놀이·운동 및 여가공간 ·건물이나 공원 등의 시설물(식재, 울타리, 표지 등) 계획 ·공공시설을 공개 계획, 주민통행로 계획

2) 주거환경개선사업

구 분	업무내용	내 용
1.현황조사	①토지이용현황조사	·지적도 복사 ·토지대장 열람 ·토지 등기부 등본 열람 ·토지이용상태 조사 ·소유자별 조서작성 ·지목별 조서작성 ·지번별 토지조서 작성
	②건물현황조사	·건물 등기부 등본 열람 ·건물 유·무허가 현황조사 ·면적조사 ·층별 현황조사 ·용도별 현황조사 ·구조별 현황조사 ·소유자별 현황조사, 건축물 조서작성
	③인구 및 산업현황 조사	·상주인구 현황조사 ·가구별 규모조사 ·직업별 인구조사 ·소득수준별 인구조사 ·주택소유별 인구조사 ·시설이용 인구조사 ·산업현황 조사
	④도시시설설치 현황조사	·상위 도시계획 상황조사 ·도시계획 현황조사 ·도시·군계획시설 설치 현황조사
	⑤교통관계조사	·도로현황과 장래계획 ·차량현황 ·보행로 및 보행자 현황 ·주차장의 설치 및 장래계획 ·철도, 버스의 현황 및 장래계획
	⑥공급처리시설 관계조사	·상수도 현황 및 계획 ·하수도 현황 및 계획 ·GAS 현황 및 계획 ·전기현황 및 계획 ·통신현황 및 계획
	⑦주민생활형편 조사	·주민의 사업추진 능력 ·생활보호대상 현황
2.기본구상	①기초조사·분석	·자연환경 ·재료원 ·보상물건 ·인문환경 ·산업경제 ·기존 및 상위계획
	②개발정비조건 및 내용설정	·개발정비방향 설정 ·계획위치 정립 ·자연환경분석 ·인문 및 산업경제분석 ·계획의 전제 ·계획내용설정

구 분	업무내용	내 용
2.기본구상 (계속)	③구상안 작성	·지역관련성 검토 ·공간구성 구상 ·토지이용 구상 ·동선체계 구상 ·녹지체계 구상
	④기술적 타당성 검토	·지리적 여건분석 ·토양현황분석 ·수계분석 ·시공기법의 검토 ·종합분석 검토
	⑤경제적 타당성 검토	·개략사업비 추정 ·인접지 토지가격 조사 ·조성원가 추정 ·분양예정가격 분석 ·투자 및 자금회수방안 검토 ·투자수익분석
3.기본계획	①토지이용계획	·도시계획사항의 결정, 변경 ·토지이용의 세분화 ·재해방지 계획 ·기타 필요사항
	②공공시설정비계획	·도로 및 공용주차장 계획 ·상하수도 설치 및 정비 ·기타(GAS, 전기, 통신)설치 및 정비
	③주택의 건설 및 부대복리 시설계획	·주택의 건설, 공급 및 관리계획 ·부대 복리시설의 설치계획 ·입주자 선정기준 및 절차 ·기타 필요사항
	④건축물의 개량	·대상건축물 ·개량범위 및 방법 ·지원방안 등
	⑤관리운영계획	·소요사업비의 추정 ·국공유지 관리, 처분방안 ·사업비 조달방안 ·투자계획 등
	⑥기타계획	·공동시설 설치계획 ·주민소득원 개발방안 ·관리 또는 환지처분계획 ·분할시행에 관한 사항 ·환경보전·재난방지 계획 ·공동이용시설 설치계획 ·교통·동선처리계획 ·구역 주변의 교육환경 보호 계획 ·구역의 분할·결합에 관한 계획 ·주택수급에 관한 사항 ·세입자 주거대책 ·안전·범죄예방 사항 ·기타 필요한 사항

3) 주거환경관리사업

구 분	업무내용	내 용
1.현황조사	①도시계획현황 및 지형현황	·용도지역·지구·구역, 도시계획 현황 ·기타 상위 및 관련계획 검토 ·경사지형 현황, 표고분석, 경사분석, 영향 예측
	②토지이용현황	·토지이용현황 ·토지소유별·지목별·과소필지 현황
	③건축물현황	·건물용도별현황 ·건물구조별·층수 현황 ·건축연도별 노후도 조사
	④인구 및 산업현황	·상주인구 및 가구규모조사 ·시설이용인구 및 취업인구조사 ·직업분포 및 소득조사 ·소유주 및 세입자 현황, 마을공동체 현황 등
	⑤정비사업에 대한 주민의 의견	·주거환경관리사업에 대한 찬성의견 ·마을 내 취약부분 의견, 소유주택 취약부분 의견 ·주거환경 만족도 및 주요 문제점, ·마을의 좋은 점(거주이유) ·지역주민 요구사항 (주민협의체에 바라는 역할) ·주택의 유지관리 및 개보수 의견, 이웃과의 관계
	⑥가로시설물 및 조경환경	·가로시설물(전신주, 나무화단, 통신선) ·조경, 보호수목 등
	⑦자연환경 및 생활환경	·생태면적률, 녹지 네트워크, 지형변동, 비오톱 ·바람 및 미기후, 휴식 및 여가공간
	⑧교통관련현황	·주변 가로망 및 교통 현황 조사 ·주차장 및 주차현황조사 ·구역내 교통·보행체계 현황 및 계획
	⑨도시시설 설치현황	·지장물 및 공공시설물조사 ·도시·군계획시설 조사 ·지역 커뮤니티 시설 현황 조사
2.기본구상	①정비목표 및 구현전략의 설정	·계획의 배경 및 목적, 범위, 수립절차, 현황 ·중점검토사항 및 계획요소 도출
	②기본방향 및 지표설정	·계획의 기본구상, 마을의 이해, 마을계획, 계획지표 설정 ·도시계획 및 설계의 제어요소 등 법적사항 검토포함 ·정비사업의 시행계획 및 시행방안 검토
3.부문별계획	①토지이용계획	·공간수요 및 적정용도 판정 ·인구 및 주택수급계획 ·토지이용계획 ·획지분할계획
	②공동이용시설 설치계획	·공동이용시설에 관한 운영주체 및 용도 ·공동이용시설 운영방안

구 분	업무내용	내 용
3.부문별계획 (계속)	③주민공동체 활성화 방안	·주민공동체 조직 구성 - 주민협의체 및 마을공동체 운영위원회 구성 지원 - 실무협의체 구축 ·주민공동체 활성화 계획 구상 및 방안 - 공동이용시설 운영 및 활성화 계획 구상 및 방안 수립 - 주민참여형 커뮤니티 프로그램 등 ·사회경제적 재생방안 - 마을축제, 지역 커뮤니티 형성, 지역문화 발굴 - 일자리창출, 협동조합 또는 마을기업 육성 등
	④주거환경관리사업 시행계획	·시행방법, 시행예정시기, 사업시행예정자, 정비사업 시행으로 증가예상 세대수
	⑤건축물의 정비·개량 및 건축시설계획	·기존 건축물의 정비·개량 계획 - 구역구분, 대지 또는 획지 구분 - 정비개량계획(동) ·건축시설계획 - 구역구분, 대지 또는 획지 구분, 위치, 주용도, 건폐율, 용적률, 높이/층수 - 주택의 규모 및 규모별 건설비율, 심의완화 사항, 건축물의 건축선에 관한 계획
	⑥도시경관·환경보전·재난방지계획	·도시경관·환경보전 계획 ·홍수 등 재해에 대한 취약 요인에 관한 검토결과 포함
	⑦구역주변의 교육환경 보호계획	·학교시설 설치 및 교육환경 보호 ·정비사업 시행으로 인한 일조장애, 통학로 단절 등에 대한 대책
	⑧기존수목의 현황 및 활용계획	·대상지내 기존수목의 현황 및 활용계획
	⑨안전·범죄예방 사항	·범죄 유발가능성이 있는 환경요소 ·청소년의 학습·놀이·운동 및 여가공간 ·건물이나 공원 등의 시설물(식재, 울타리, 표지 등)계획 ·공공시설을 공개 계획, 주민통행로 계획
	⑩재원조달방안	·사업유형 및 정비예정구역별 방안 검토 ·시 예산, 제3섹터 방식 및 민간자본 등 조달계획
	⑪환경성검토	·환경현황 조사·분석 및 환경성 검토 내용 반영 ·환경성 예측 및 저감방안
	⑫교통성검토	·대상구역 및 주변지역의 차량 및 보행자에 대한 교통처리계획 및 시설계획, 교통성 검토 내용 반영
4.주민워크샵	①주민워크샵 등	·주민워크샵 / 주민회의

4) 구역해제 및 관리방안

구 분	업무내용	내 용
1.현황조사	①주민·산업의 현황	·세대수 및 인구수 ·인구밀도, 호수밀도 ·거주가구 및 세입자 현황 ·정비구역안의 유·무형 문화유적, 보호수목현황 및 지역 유래
	②토지·건축물의 이용·소유현황	·토지의 이용 및 소유현황 ·토지의 지목별·규모별 현황 ·건축물의 이용 및 소유현황 ·건축물의 허가유무·노후불량 건축물현황 ·건축물의 용도, 구조, 규모 및 건축경과(준공)년도별 현황
	③정비기반시설의 설치현황	·도로, 공원, 녹지 ·도시·군관리계획상 토지이용계획 현황
	④정비구역·주변지역의 교통상황	·주변교통체계조사 ·주요 가로망·도로
	⑤토지·건축물의 가격·임대차현황	·임대료 및 지가조사 ·토지 및 건물가격의 변동 추이 ·주민생활형편 조사
	⑥개략 사업성 분석	·개략사업비 추정 ·인접지 토지가격 ·조성원가 추정, 분양예정가격 분석 ·투자 및 자금회수방안 검토, 투자수익분석
	⑦정비사업에 대한 주민의 의견	·정비사업 시행계획 및 시행방법에 대한 주민(소유주)의견조사 ·토지 등 소유자의 정비구역지정에 관한 동의현황
2.구역해제에 따른 문제점 분석	①토지이용계획	·인근 구역들에 미치는 악영향과 주민 부담 ·존치구역 지정, 문화 · 기반시설 계획의 재편 등
	②기반시설 및 공공용지 분담계획	·해제 구역의 인접 구역과의 기반시설 분담 ·기반시설을 폐지/축소, 부담계획
	③교통처리 계획	·촉진사업 시행 유 · 무(구역해제 여부 포함)에 따른 교통량 증 · 감 ·구역해제에 따른 주변지역의 교통량과 도로용량 등 주변 간선교통 체계와 연계된 가로망 계획
3.구역해제에 따른 대책검토	①상위·주변지역 계획과 정합성 유지방안	·상위계획과 주변지역계획과의 문제점 유형화 ·도시정비적 측면에서 인접지역을 고려한 정합성 유지방안 마련
	②정비기반시설의 조정방안	·기 수립된 기반시설 분담계획 검토 ·해제 구역의 주민과 주변 사업구역에 피해를 최소화 할 수 있는 방안을 제시
	③기존 건축물의 정비·개량 계획	·해제 구역의 난개발 방지를 위한 건축 · 개발행위허가에 대한 가이드라인을 계획
	④환경보전·재난방지계획	·기존 도시공원 및 녹지 공간, 광역적 녹지체계와 구역별 녹지체계 ·일조, 에너지 등 ·화재, 지진, 홍수 등의 재해 등

구 분	업무내용	내 용
3.구역해제에 따른 대책검토(계속)	⑤대책 반영에 따른 소요비용 비교 검토	·해제 구역 내의 기반시설 설치에 소요되는 투자비 (건축물·토지 보상비, 설치비 등) 내역 및 재원확보 방안 마련 ·소요 사업비의 국·시비, 구비, 민간비용 등으로 구분
	⑥공공 지원 대책 검토	·해제 구역에 대한 난개발방지 대책과 기반시설 또는 앵커시설 지원을 검토 ·사업 시행이 필요한 구역의 관리방안을 수립
	⑦관계법령에 따른 후속 추진사항 검토	·인접 구역의 기반시설 계획과의 연계성 등을 분석 ·해제구역의 지형 · 지세 및 기 계획된 기반시설 설계 자료 등을 통해 예상되는 장애를 최대한 고려하여 기반시설의 신설 여부 ·해제 구역의 주민과 주변 사업구역에 피해를 최소화 할 수 있는 방안을 제시

3-6-3 가로주택정비사업(사업계획)

구 분	업무내용	내 용
1.현황조사	①가로주택정비사업 충족 여부	·가로구역 여부 및 면적 ·사업구역 면적 ·세대수, 노후도
	②도시·군관리계획 현황	·용도지역, 용도지구 ·지구단위계획구역 지정 여부 및 내용 ·기타
	③토지 현황	·지목 ·개별필지면적
	④건축물 현황	·용도, 층수, 용적률, 총호수, 주택면적 ·근린생활시설 면적 ·공동주택의 경우 각 세대별 전용면적 및 토지지분
	⑤공시가격	·개별공시지가 ·개별주택공시가격
2.기본구상	①주택건설예정 호수·세대수	·주택건설 예정 호수 및 세대수
	②시행구역의 범위·지번·지목 및 등기명의자	·가로구역 및 가로주택정비사업 시행구역의 범위·지번·지목 및 등기명의자
	③도시·군관리계획의 용도지역	·도시·군관리계획의 용도지역
	④대지·주변현황 사업계획서	·대지 및 주변현황을 적은 사업계획서
	⑤위치도 및 현황도	·정비구역의 위치도 ·정비구역의 현황사진
	⑥토지·건축물 지적현황도	·정비구역 안의 토지 및 건축물의 지형이 표시된 지적현황도

3-6-4 사업시행계획

구 분	업무내용	내 용
1. 토지 및 건물 권리 조사	①지적도 복사, 토지 및 건물 대상 및 등기부 열람	·지적도 복사 ·토지 및 건축물대장 열람 ·토지 및 건축물등기부 열람 ·토지 및 건축물대장 작성 및 집계
	②고정자산세, 과세표준액 등 조사	·과세표준액 조사 및 조서작성 ·차지권자별 토지조서 작성
2.기본설계		
3.자금계획	①개략사업비 산정	·총공사비 개략산정 ·보상비 산정 ·사무비 산정 ·차입금이자 산정
	②수지계획	·재원별 수입지출 조사 ·수지계산서 작성 ·연도별 세입세출 자금계획
4. 사업시행계획	①사업설명서	·시행목적 ·토지 및 건축물에 대한 권리자별 권리명세 ·개수가 필요한 건축물 명세 및 개수계획 ·지장물에 대한 명세 ·가수용계획 ·공동구의 설치에 관한 사항 ·재개발사업시행전후의 공공시설 조서 및 시행전 감정평가서와 시행후 설치비용 ·건축계획
	②부속도서	·부속서류의 수집 ·부속도 작성 ·규약, 시행규정안의 작성
	③인가신청서	·사업의 명칭, 설계설명서, 시행기간 ·부속도서의 정리, 설계도 편집
5.실시설계		

3-6-5 관리처분계획

구 분	업무내용	내 용
1.분양설계기준	①토지 및 건물 권리조사 보정	·토지 및 건축물별 등기열람 및 조서작성 (부동산 등기 및 무허가 건물확인원 조사) ·국공유지의 연고권 결정 ·소유자별 목록 보정 ·동별, 지목별 집계수정 ·지적도 수정
	②종전토지지적의 결정	·구역계의 검토 및 필지면적 계산 ·구역계 면적의 갱정률 산정 및 지적 결정

구 분	업무내용	내 용
1.분양설계기준 (계속)	③토지 및 건물가격 평가기준 작성	·분양예정의 대지 또는 건축시설의 추산액과 종전의 토지·건물 가격평가기준 작성
	④분양설계기준의 작성	·자료조사 및 기준안 작성(특별지의 처리)
2.토지평가	①자료조사	·대상시설 보완조사 및 도면작성
	②정리전후 노선가 설정	·노선가 설정도로의 검토 확정 ·계수배치의 검토 및 결정 ·정리전후 노선가 계산 ·정리전후 노선가도 작성 ·지수계산 ·증가율의 계산 ·노선가 계산서 및 자료정리
	③정리전 각필지 평가	·평가계산용 도면작성 ·평가계산 및 집계서 ·각 필지 평가도 작성
	④정리후 가구평가	·평가계산용 도면작성 ·환지위치 및 형상상정 ·평가구분 결정 ·가구평가 계산서 정리 ·평가계산 및 집계 ·평가도 작성
	⑤증진율 계산	·정리전 총평가지수 보정 ·정리후 총평가지수 보정 ·검토 및 계산
3-1.비례평가식 환지 (분양)계산	①비례율 산정	·사업비 부담지수 산출 ·비례율 계산 ·시산 조정 결정
	②권리지수 산정	·분양계산서 정비 ·권리지수 계산 및 집계
	③분양배당지수 및 지적산출	·배당지수 산정 ·분양지적 계산
3-2.절충식 환지 (분양)계산	①공통부담률 계산	·부여지적의 계산 및 집계 ·연도부담지적의 계산 및 집계 ·공통부담률의 계산
	②잠정환지지적	·분양계산서 ·잠정분양계산용 도면작성 ·잠정분양률표의 작성 ·잠정분양지적의 계산 및 집계
	③잠정환지의 평가	·평가계산 및 집계
	④증가배분율의 계산	·증가배분기준지수 계산 ·사업비부담지수 산출 ·증가배분율 계산
	⑤권리지수 산정	·권리지수의 산정 및 집계
3-3.면적식 환지 (분양)계산	①공통부담률 계산	·가산지적의 계산 및 집계 ·연도부담지적의 계산 및 집계 ·연도부담률 계산 ·공통부담률의 계산

구 분	업무내용	내 용
3-3.면적식 환지(분양) 계산	②급지별 공통부담률 계산	·급지별 필지면적 또는 지수계산 ·사업비 부담지수 산출 ·급지별 공통부담률 계산
4.환지(분양) 할당설계	①가할당(평가식에 한함)	·필지조사 및 할당위치의 검토와 분양설계도 작성 ·가할당과 계산
	②분양할당	·할당용 도면작성 ·할당위치단위지수 계산 및 할당지적의 계산과 검토 ·각 필지감보율의 계산 및 검토 ·할당지적 조서 작성 ·평가계산용(급지별) 면적 작성 ·지수계산 및 청산지수 산출 (권리면적 및 과부족 계산) ·평가조서 작성(급지별 조서) ·할당오차의 검토
	③분양할당 수정	·원안 작성후의 변경정리 ·변경할당 단위지수(면적)계산 ·각필지 감보율의 수정 ·필지별 집계의 수정 ·환지할당수정도 작성
	④가구별 분양조서 및 할당도	·가구별 획지별 조서 ·가구별 분양할당도
	⑤공람에 따른 분양계산의 보완	·분양계산 보완 ·분양할당 보완 ·분양할당도 수정 ·분양지정조서의 보완
	⑥분양원안 설명	·가분양 원안 설명
5.환지(분양) 예정지지정	①분양예정지 지정서 작성	·종전 토지의 위치·지목·면적과 분양지의 위치, 분양면적, 각각의 평가액 및 징수·교부액 등 조서작성 ·분양예정지 지정도 작성
6.분양설계서	①인가신청도서 작성	·분양설계 기준 ·자금운용계획서 ·관리처분계획 대상물건조서 ·종전 토지 및 건축물의 명세 및 가격과 분양예정 대지 또는 건축시설의 규모 및 추산액 ·종전토지, 건축물에 관한 소유권외의 권리명세 ·보류지의 명세와 추산가액 및 처분방법 ·일반 분양대지 또는 건축시설의 명세와 추산가액 및 처분방법 ·임대주택의 명세와 추산가액 및 처분방법 ·임대주택 공급대상 세입자 명부 ·청산대상 토지 등의 명세와 청산방법 ·새로이 설치되는 공공시설의 명세와 용도가 폐지되는 공공시설의 명세 ·분양설계도면 ·분양예정지지정 도명 ·종전토지의 지적 또는 임야 도면

3-7 표준성과품

3-7-1 도시 및 주거환경정비 기본계획

성과구분	표준성과도서			비 고
	구 분	규 격	제출부수	
설계도	·기본계획 총괄도 ·정비예정구역 표시도	1/3,000 또는 1/5,000	1부 〃	도시별 적정축척 사용
보고서	·기본계획보고서 ·기초조사 및 계획수립 관련 자료집	발주자와 협의 결정	발주자와 협의결정	

주 : ①제출부수 및 성과품 종류가 증가할 경우에는 증가배수에 해당하는 작업품과 비용을 가산한다.
②계획보고서 및 기타 관련자료의 규격 및 제출부수는 발주자와의 협의에 의하여 비용을 산정한다.

3-7-2 구역지정(정비계획)

1. 주택재개발사업·주택재건축사업·도시환경정비사업

성과구분	표준성과도서			비 고
	구 분	규 격	제출부수	
현황도	·토지이용현황도 ·건물현황도 ·도시시설현황도	1/3,000 또는 1/500 〃 〃	1부 〃 〃	구역지정시 현황측량이 필요할 경우 발주자와 협의하여 별도 작성제출
계획도	·토지이용계획도 ·건축배치계획도 ·공급처리시설계획도 ·종합계획도	1/3,000 또는 1/500 〃 〃 〃	〃 〃 〃 〃	
보고서	·계획보고서	발주자와 협의결정	발주자와 협의결정	
조감도	·계획구역 조감도	발주자와 협의결정	1식	지역규모에 따라 조정 가능

주 : ①제출부수 및 성과품 종류가 증가할 경우에는 증가배수에 해당하는 작업품과 비용을 가산한다.
②계획보고서 및 기타 관련자료의 규격 및 제출부수는 발주자와의 협의에 의하여 비용을 산정한다.

2. 주거환경개선사업·주거환경관리사업·구역해제 및 관리방안

성과구분	표준성과도서			비 고
	구 분	규 격	제출부수	
현황도	·토지이용현황도 ·건물현황도 ·도시시설현황도	1/3,000 또는 1/500 〃 〃	1부 〃 〃	구역지정시 현황측량이 필요할 경우 발주자와 협의하여 별도 작성제출
계획도	·토지이용계획도 ·건축배치계획도 ·공급처리시설계획도 ·종합계획도	1/3,000 또는 1/500 〃 〃 〃	〃 〃 〃 〃	
보고서	·계획보고서	발주자와 협의결정	발주자와 협의결정	
조감도	·계획구역 조감도	발주자와 협의결정	1식	지역규모에 따라 조정가능

주 : ①제출부수 및 성과품 종류가 증가할 경우에는 증가배수에 해당하는 작업품과 비용을 가산한다.
②계획보고서 및 기타 관련자료의 규격 및 제출부수는 발주자와의 협의에 의하여 비용을 산정한다.

3-7-3 가로주택정비사업(사업계획)

성과구분	표준성과도서			비 고
	구 분	규 격	제출부수	
현황도	·토지이용현황도 ·건물현황도 ·도시시설현황도	1/3,000 또는 1/500 〃 〃	1부 〃 〃	구역지정시 현황측량이 필요할 경우 발주자와 협의하여 별도 작성제출
계획도	·토지이용계획도 ·건축배치계획도 ·공급처리시설계획도 ·종합계획도	1/3,000 또는 1/500 〃 〃 〃	〃 〃 〃 〃	
보고서	·계획보고서	발주자와 협의결정	발주자와 협의결정	
조감도	·계획구역 조감도	발주자와 협의결정	1식	지역규모에 따라 조정가능

주 : ①제출부수 및 성과품 종류가 증가할 경우에는 증가배수에 해당하는 작업품과 비용을 가산한다.
②계획보고서 및 기타 관련자료의 규격 및 제출부수는 발주자와의 협의에 의하여 비용을 산정한다.

3-7-4 사업시행계획

성과구분	성과항목	표준성과도서					
		도	원본	사본	도	원본	사본
1.토지 및 건물 권리조사	①지적도 복사, 토지 및 건물대장 및 등기부열람	지적도 복사	1	1	토지 및 건축물대장, 등기부열람서 토지 및 건축물대장조서 소유자별 조서 소유자별 목록	1 1 1 1	
	②도면작성	지적 종합도	1				
	③고정자산세 과세표준액 등 조사				과세표 조서 차지권 토지조서	1 1	1 1
2.자금계획	①개략사업비산정				사업비산정 조서	1	5
	②수지계획				자금 계획서	1	5
3.사업시행 계획서	①사업설명서				사업 설명서	1	5
	②부속도서	첨부도 1 식	1		조례, 규정	1	5
	③인가신청서	설계도		5	인가 신청서		5

주 : ①제출부수 및 성과품 종류가 증가할 경우에는 증가배수에 해당하는 작업품과 비용을 가산한다.
②계획보고서 및 기타 관련자료의 규격 및 제출부수는 발주자와의 협의에 의하여 비용을 산정한다.

3-7-5 관리처분계획

성과구분	성과항목	표준성과도서					
		도	원본	사본	도	원본	사본
1.분양설계기준	①토지 및 건물 권리 조사보정	수정지적도	1		토지및건물수정조서 소유자별수정조서	1 1	
	②종전 토지지적의 결정	지구계분할도	1	1	개정지적조사	1	1
	③토지 및 건물가격 평가기준의 작성				토지및건물평가기준	1	
	④분양설계기준의작성				분양설계기준안	1	
2.토지평가	①자료조사	평가대상 시설도	1				
	②정리전후 노선가 설정	정리전후 노선도	1	1	정리전후노선가계산서	1	
	③정리전 각필지평가	평가계산도	1		각필지평가계산서	1	
	④정리후 가구평가	가구평가도	1	1	가구평가계산서	1	
	⑤증진율 산정				증진율계산서	1	
3-1.비례평가식 분양계산	①비례안산정				비례율계산서	1	
	②권리지수산정						
	③분양배당지수 및 지적산출						

성과구분	성과항목	표준성과도서					
		도	원본	사본	도	원본	사본
3-2.절충식 환지계산	①공통부담률계산	공통부담 계산도	1		공통부담계산서	1	
	②잠정환지지적				잠정분양지적계산서	1	
	③잠정환지의 평가				잠정분양평가계산서	1	
	④증가배당률산정				증가배당률계산서	1	
	⑤권리지정산정				권리지수계산서	1	
3-3.면적식 환지계산	①공통부담률계산	가산지적 계산도 공통부담 계산도	1 1		가산지적계산서 연도부담계산서 공통부담률계산서	1 1 1	
	②급지별공통부담률계산	급지별구분도	1		급지별지적조서 급지별공통부담률계산서	1 1	
4.환지(분양) 할당설계	①가할당(평가식에 한함)	가할당도	1		가할당계산서	1	
	②분양할당	할당계산도	1		할당계산서※ 지수계산서(급지별계산서) 평가조서※※	1 1 1	
	③분양할당예정	수정할당도	1		수정할당계산서	1	
	④가구별 분양조서 및 할당도	가구별분양 할당도	1		가구별획지조서	1	1
	⑤공람에 따른 분양 계산의 보완	수정할당도	1		수정할당계산서	1	
	⑥분양원안설명						
5.환지(분양)예정지 지정	①분양예정지지정서	환지(분양) 지정도	1	2	분양예정지지정서	1	
6.분양설계서		환지(분양)도	1		분양지정조서 청산금(면적)명세서 인가신청서	1 1 5	

주 : ①제출부수 및 성과품 종류가 증가할 경우에는 증가배수에 해당하는 작업품과 비용을 가산한다.
②계획보고서 및 기타 관련자료의 규격 및 제출부수는 발주자와의 협의에 의하여 비용을 산정한다.
※ 급지별 구분이 없을때는 제외, ※※ 평가식에 한함

제4절 리모델링 기본계획

4-1 정 의

○ 향후 지속적으로 늘어나는 노후 공동주택의 원활한 리모델링 추진을 통하여 도시의 주거환경을 개선하고 거주민의 삶의 질을 향상을 위한 목표와 기본방향을 제시하는 계획으로서, 세대수 증가형 리모델링으로 인한 도시과밀, 이주수요 집중 등을 체계적으로 관리하기 위하여 수립하는 계획을 말한다.

4-2 자료제공의 전제

○ 당해 계획의 수립에 필요한 모든 관련자료는 원칙적으로 발주자가 제공하는 것으로 하되, 발주자 등이 보유하지 않는 자료는 엔지니어링사업자가 조사·수집한다.

○ 발주자가 제공하지 못하는 자료의 조사에 있어서는 그 규모·내용에 의거하여 별도의 엔지니어링사업대가를 산정하여 엔지니어링사업자가 수행하며, 당해 관련자료의 기밀성과 광범위한 자료가 요구될 경우에는 조사·분석에 필요한 상당기간과 자료수집비용이 전제되어야 한다.

4-3 업무범위와 추진과정

4-3-1 업무범위

○ 생활권별 리모델링 대상 공동주택 및 기반시설 현황 파악 등을 통하여 유형별 리모델링 수요를 과학적으로 분석·예측하고, 세대수 증가형 리모델링으로 인한 도시과밀 및 이주수요 집중을 체계적으로 관리할 수 있는 방안의 제시 등을 주요 업무범위로 한다.

4-3-2 추진과정

○ 타부처(관계기관)와 협의나 전문가 자문 등의 기술협의에 소요되는 기간은 과업수행기간에서 제외하여 그 소요기간 만큼 과업수행기간을 연장하여야 한다.

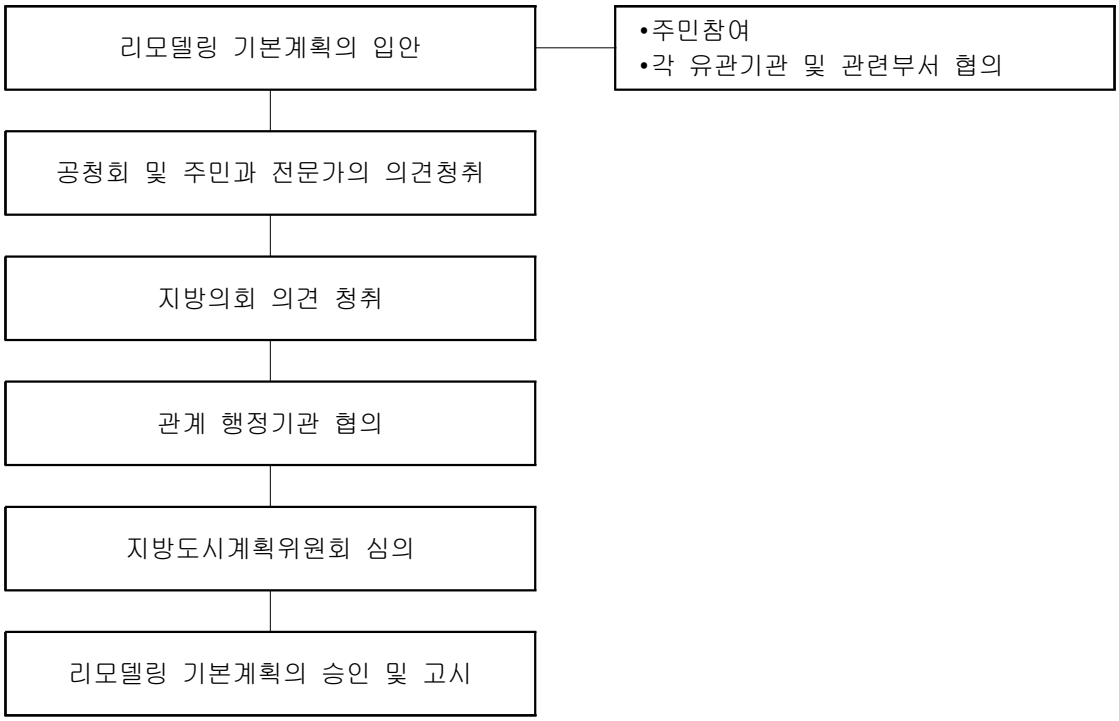

4-4 품 산정의 원단위 산정과 기준

4-4-1 표준품 산정내역

○ 표준품 산정의 기준이 되는 비목은 제1장 총칙에서 제시한 비목을 중심으로 하였으며, 이는 리모델링 기본계획에 필요한 사항만을 대상으로 한다.

○ 표준품 산정의 기본이 되는 직접인건비 품의 작업항목별 보할은 업무의 난이도를 감안하여 설정토록 한다.

종 별		내 용		단 위	비 고
직접비	직접인건비	1.기초조사	①도시 일반 현황 ②관련계획 ③공동주택 현황 ④기반시설 현황	인·일 〃 〃 〃	
		2.기본계획	①계획의 목표 및 기본방향 ②리모델링 수요 예측 ③기반시설 영향 검토(일반) ④기반시설 영향 검토(특정지역) ⑤단계별 리모델링 시행방안 ⑥도시경관 관리방안 ⑦공동주택 저에너지·장수명화 방안 ⑧리모델링 지원방안	〃 〃 〃 〃 〃 〃 〃 〃	(필요시,별도품) (필요시) (필요시)
		3.성과품 작성	①보고서작성 및 편집 ②관련도서작성	〃 〃	
		4.기술협의	①공청회 / 주민설명회 ②주민간담회 / 시민계획단 ③위원회 심의 지원 ④관계기관 협의	〃 〃 〃 〃	
	직접경비	여비, 인쇄비, 조감도, 회의준비비, 현장운영비 등		식	제1장 총칙참조
간접비	제경비	(직접인건비)×120%		〃	〃
	기술료	(직접인건비+제경비) ×30%		〃	〃

4-4-2 산정기준

1. 계획·기준인구의 설정

○ 기준인구는 계획수립대상(특별시, 광역시, 대도시) 도시의 평균인구를 고려하여 150만인으로 하였으며, 직능별 직접인력 소요원단위는 기 작성된 도시・주거환경정비기본계획 등의 투입기술자 비율을 감안하여 설정하였다.

○ 계획인구는 계획기준년도의 당해 도시 인구수(안전행정부 자치단체별 인구수)를 원칙으로 한다.

2. 표준품의 산정방법

○ 표준품의 적용에 있어 기준인구와 계획인구의 차이에 따른 품 산정은 아래의 수정식에 따라 기준인구의 소요작업량을 수정하여 산정한다.

○ 소요작업량 = 기준인구 소요작업량 × 인구보정계수(α)

○ 업무에 필요한 자료는 자료제공의 전제에 따라 발주자가 제공이 불가능하여 엔지니어링사업자에게 작성토록 할 경우 그의 내용에 따라 실비로 계상한다.

○ 업무의 수행에 필요한 각종 평가업무(교통, 환경, 재해, 경관)는 제8장 도시평가의 해당품을 별도 적용하며, 측량·전산처리·시험 등의 경비에 대하여는 실비로 가산한다.

○ 리모델링 기본계획의 기초조사는 도시・군기본계획의 해당품을 적용한다.

3. 계획안의 수정과 과업중지에 따른 품 산정방법

○ 계획안이 작성되고 공청회, 주민공람, 의회보고 등 기술협의과정을 거쳐 계획안이 확정된 후 발주자의 사정에 의하여 계획안이 일부변경 · 재작업이 수행되는 경우에는 그 변경·재작업의 정도에 따라 엔지니어링사업대가의 50～100% 수준에서 비용을 추가 지급하여야 한다.

○ 과업수행 중 발주자의 사정에 따른 과업 중단으로 인해 정부 회계연도가 경과되어 현저한 비용의 차이가 발생하였을 경우에는 엔지니어링사업대가를 당해 신년도의 노임단가를 기준으로 재산정하여야 한다.

4-4-3 단위별 변화수정과 보정

1. 인구의 대소에 대한 작업량 보정계수 산정

○ 도시의 계획인구가 기준인구를 초과하거나 못 미치는 경우의 직접인력 소요작업량의 산정을 위한 보정계수(α)는 다음의 식에 의해 산정한다.

$$\alpha = \left(\frac{\text{계획인구}}{\text{기준인구}}\right)^{0.6} = \left(\frac{A}{150}\right)^{0.6}$$

α = 보정계수
A = 계획인구(만인)

계획단위 인구별 보정계수

계획인구(만인)	보정계수 (α)	계획인구(만인)	보정계수 (α)
50	0.517	100	0.784
60	0.577	150	1.000
70	0.633	200	1.188
80	0.686	300	1.516
90	0.736	400	1.801

주 : 계획인구 50만인 미만인 경우에는 계획인구 50만인을 기준으로 하여 산정한다.

2. 직접인건비 소요 작업량 산정

○ 계획인구의 대소에 따른 직접인력 소요작업량의 산정방법은 아래와 같이 기준인구의 직능별 직접인력 소요작업량에 계획단위 보정계수(α)를 곱하여 산출한다.

구 분	기준인구 (만인)	총작업량(인·일)					
		기술사	특 급	고 급	중 급	초 급	보조원
리모델링 기본계획	150	47.3α	74.5α	175.4α	296.2α	430.3α	425.3α

4-5 표준단위 업무분류와 원단위

기술업무의 직능별 직접인력 소요작업량(인구 150만인 기준)

(단위 : 인·일/표준단위)

구 분	업무내용	표준 단위	소요인력						비고
			기술사	특 급	고 급	중 급	초 급	보조원	
1.기초 조사	①도시 일반현황	150만인	5.9	9.5	39.7	59.9	99.4	107.3	
	②관련계획	150만인	1.3	2.1	2.8	7.8	7.8	10.5	
	③공동주택현황	150만인	1.0	2.0	4.9	12.7	15.2	17.8	
	④기반시설현황	150만인	2.8	4.4	13.3	18.5	21.5	21.1	
	소 계		11.0	18.0	60.7	98.9	143.9	156.7	
2.기본 계획	①계획의 목표 및 기본방향	150만인	5.4	5.8	11.6	19.2	28.8	18.4	주1
	②리모델링 수요 예측	150만인	5.4	8.7	17.4	29.1	43.2	41.4	
	③기반시설 영향 검토(일반)	150만인	4.5	7.2	14.7	24.3	36.0	34.5	
	④기반시설 영향 검토(특정지역)	150만인	-	-	-	-	-	-	
	⑤단계별 리모델링 시행방안	150만인	3.0	5.0	9.8	16.2	23.8	23.0	
	⑥도시경관 관리방안	150만인	3.6	6.3	11.7	19.8	29.1	27.6	
	⑦공동주택 저에너지·장수명화 방안	150만인	3.0	5.0	9.8	16.2	23.8	23.0	
	⑧리모델링 지원방안	150만인	2.6	4.2	7.8	13.2	19.4	18.4	
	소 계		27.5	42.2	82.8	138.0	204.1	186.3	
3.성과 품 작성	①보고서작성 및 편집	150만인	6.0	9.4	21.2	35.4	35.1	23.3	
	②관련도서작성	150만인	2.8	4.9	10.7	23.9	47.2	59.0	
	소 계		8.8	14.3	31.9	59.3	82.3	82.3	
총 계			47.3	74.5	175.4	296.2	430.3	425.3	
4.기술 협의	①공청회/주민설명회	1식	2.0	2.0	2.0	4.0	4.0	4.0	주2
	②주민간담회/시민계획단	1식	2.0	2.0	2.0	4.0	4.0	4.0	
	③위원회심의 지원	1식	2.0	2.0	2.0	4.0	4.0	4.0	
	④관계기관 협의	1식	2.0	2.0	2.0	4.0	4.0	4.0	
	소 계		8.0	8.0	8.0	16.0	16.0	16.0	

주 : ①기반시설 영향 검토(특정지역) 업무는 제8장 도시관련평가의 교통성검토 업무로 별도 계상한다.

②기술협의는 2회 이내 기준이며, 횟수가 늘어날 경우 증가배수에 해당하는 작업품과 비용을 가산한다. (필요항목 선택적 적용)

③각종영향성검토 및 각종영향평가업무는 별도의 엔지니어링활동업무로 계상한다.

4-6 주요업무내용

구 분	업무내용	내 용
1.기초조사	①도시 일반현황	·연령별·세대별 인구의 구성, 변화 추이
	②관련계획	·시·도 주택종합계획, 도시·군기본계획, 도시 및 주거환경정비기본계획 등 관련계획
	③공동주택현황	·공동주택의 위치, 용도지역, 준공연수, 동수, 세대수, 주택 면적별 구성, 대지면적, 건축연면적, 층수, 용적률, 건폐율, 주차장수(지하, 지상) ·주요 수선이력, 장기수선충당금 규모, 주택가격, 주민의사, 안전진단 기록, 단지배치도, 현장조사 사진
	④기반시설현황	·도로, 상하수도, 공원·녹지, 교육시설 등 주요 기반시설의 설치 및 계획 현황
2.기본계획	①계획의 목표 및 기본방향	·노후 공동주택의 주거환경개선 목표 설정 ·리모델링의 기본방향 제시
	②리모델링 수요 예측	·노후공동주택의 일반적 유지관리, 세대수 증가형 리모델링, 세대수 증가형 외 리모델링, 재건축 구분 ·세대수 증가형 리모델링의 목표연도 및 단계별, 권역별 수요 예측
	③기반시설 영향 검토(일반)	·권역별 교통시설(도로, 주차장 등), 상·하수도시설, 공원·녹지시설, 교육시설(학교)에 미치는 영향 검토 ·권역별 기반시설 확충 방향성 제시 ·지구단위계획의 수립·변경 방안 제시 ·단지내 주차장 확보 방안 제시 ·커뮤니티시설 등 부대복리시설 설치 가이드라인 제시
	④기반시설 영향 검토(특정지역)	·개략적 교통영향 검토 및 개선방안
	⑤단계별 리모델링 시행방안	·권역별 리모델링 허가총량 설정 및 우선순위원칙 제시
	⑥도시경관 관리방안	·건축물 외관의 형태, 색채, 높이·스카이라인 등에 대한 기준 제시
	⑦공동주택 저에너지·장수명화 방안	·단계별·부문별 에너지 저감형 리모델링 유도방안 제시 ·단계별·부문별 장수명화 방안 제시
	⑧리모델링 지원방안	·해당 지자체 및 중앙행정기관의 지원제도와 연계

4-7 표준성과품

성과구분	표준성과도서			비 고
	구 분	규 격	제출부수	
계획도	·리모델링 기본계획 총괄도	1/25,000 또는 1/50,000	1부	도시별 적정축척 사용
보고서	·리모델링 기본계획 보고서 ·기초조사 및 계획수립 관련 자료집	발주자와 협의 결정	발주자와 협의결정	

주 : ①제출부수 및 성과품 종류가 증가할 경우에는 증가배수에 해당하는 작업품과 비용을 가산한다.
②계획보고서 및 기타 관련자료의 규격 및 제출부수는 발주자와의 협의에 의하여 비용을 산정한다.

제7장 도시경관

제1절 도시경관계획

제2절 지구경관계획

제3절 사회기반시설사업 등의 경관심의

제1절 도시경관계획

1-1 정 의

○ 도시경관계획은 경관법에 근거한 경관계획과 국토의 계획 및 이용에 관한 법률에 따른 도시ㆍ군기본계획과 도시ㆍ군관리계획의 경관부문계획으로 구분하여 경관품셈기준을 책정한다.

1-1-1 시ㆍ군경관계획

○ 경관법에 근거한 경관계획은 「경관법」제6조에 따라 국토교통부장관이 수립하는 경관정책기본계획과 「경관법」제7조에 따라 도(특별자치도), 특별시(특별자치시), 광역시, 시, 군, 경제자유구역청 관할 구역, 자치구를 대상으로 수립하는 경관계획을 의미하며, 경관계획수립지침에 의거하여 경관계획과 특정경관계획으로 구분할 수 있다.

○ 시·군경관계획 품셈기준은 시나 군을 대상으로 수립하는 경관계획을 기준으로 하며 도(특별자치도), 특별시(특별자치시), 광역시, 시, 군, 경제자유구역청 관할 구역, 자치구를 대상으로 수립하는 경관계획에 적용할 수 있다.

○ 특정경관계획 수립 시, 특정지역을 대상으로 수립하는 경우에는 제2절 지구경관계획의 경관상세계획 품셈기준을 준용하고, 특정경관유형이나 경관요소에 대하여 수립하는 경우 시ㆍ군 경관계획 품셈기준의 70% 이상 준용하여 책정한다.

○ 「경관법」제15조에 따라 경관계획 재정비 시, 시ㆍ군 경관계획 품셈기준의 70% 이상 준용하여 책정한다.

○ 경관법에 의한 국토차원의 경관정책기본계획은 연구용역 기준을 적용하거나 필요한 경우 도시경관계획의 품셈을 적용할 수 있다.

1-1-2 도시ㆍ군경관부문계획

○ 국토의 계획 및 이용에 관한 법률에 따른 도시ㆍ군기본계획의 경관 및 미관계획과 도시ㆍ군관리계획(재정비)의 경관부문계획은 도시ㆍ군 경관부문계획 품셈기준을 따른다.

○ 도시ㆍ군관리계획(단위) 수립 시, 경관검토서를 별도로 작성하는 경우 제8장 제6절 경관성검토 품셈기준을 준용하여 별도로 책정한다.

도시경관계획의 체계

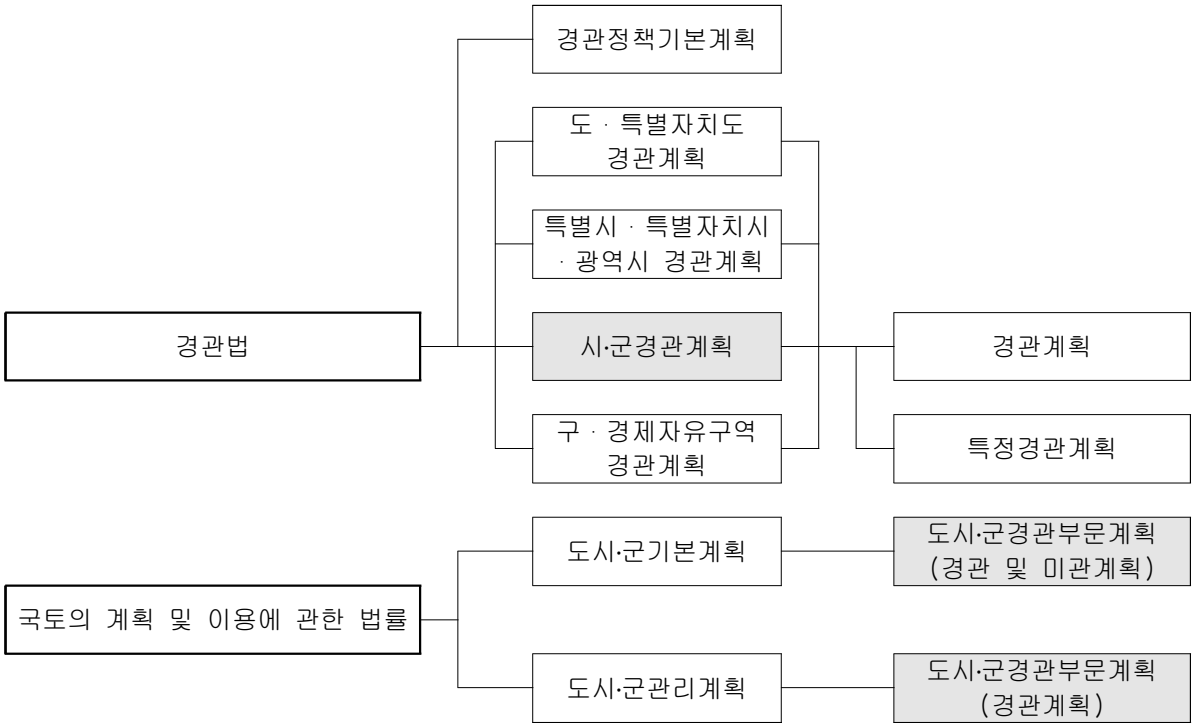

1-2 자료제공의 전제

○ 당해 계획의 수립에 필요한 모든 관련 자료는 원칙적으로 발주자가 제공하는 것으로 하되, 발주자가 보유하지 않은 자료는 엔지니어링사업자가 수집한다.

○ 발주자가 제공하지 못하는 자료의 조사에는 그 규모·내용에 의거하여 별도의 엔지니어링사업대가를 산정하여 엔지니어링사업자가 수행하며, 당해 관련 자료의 보안이나 광범위한 자료가 요구될 경우는 조사·분석에 필요한 기간과 자료수집비용이 전제되어야 한다.

1-3 업무범위와 추진과정

1-3-1 업무범위

○ 시·군경관계획은 경관계획수립지침을 준용하여 대상지역의 특성에 부합하도록 계획을 수립한다.

○ 도시·군경관부문계획은 도시·군기본계획수립지침과 도시·군관리계획수립지침, 경관계획수립지침을 준용하여 작성한다.

1-3-2 추진과정

○ 관계법과 지침에 따라 절차를 이행하며 관계기관과의 협의, 전문가 자문, 공청회, 의회의견청취, 심의 등에 소요되는 기간은 과업수행기간에서 제외하여 그 소요기간 만큼 과업수행기간을 연장하여야 한다.

시 · 군경관계획 업무 추진과정

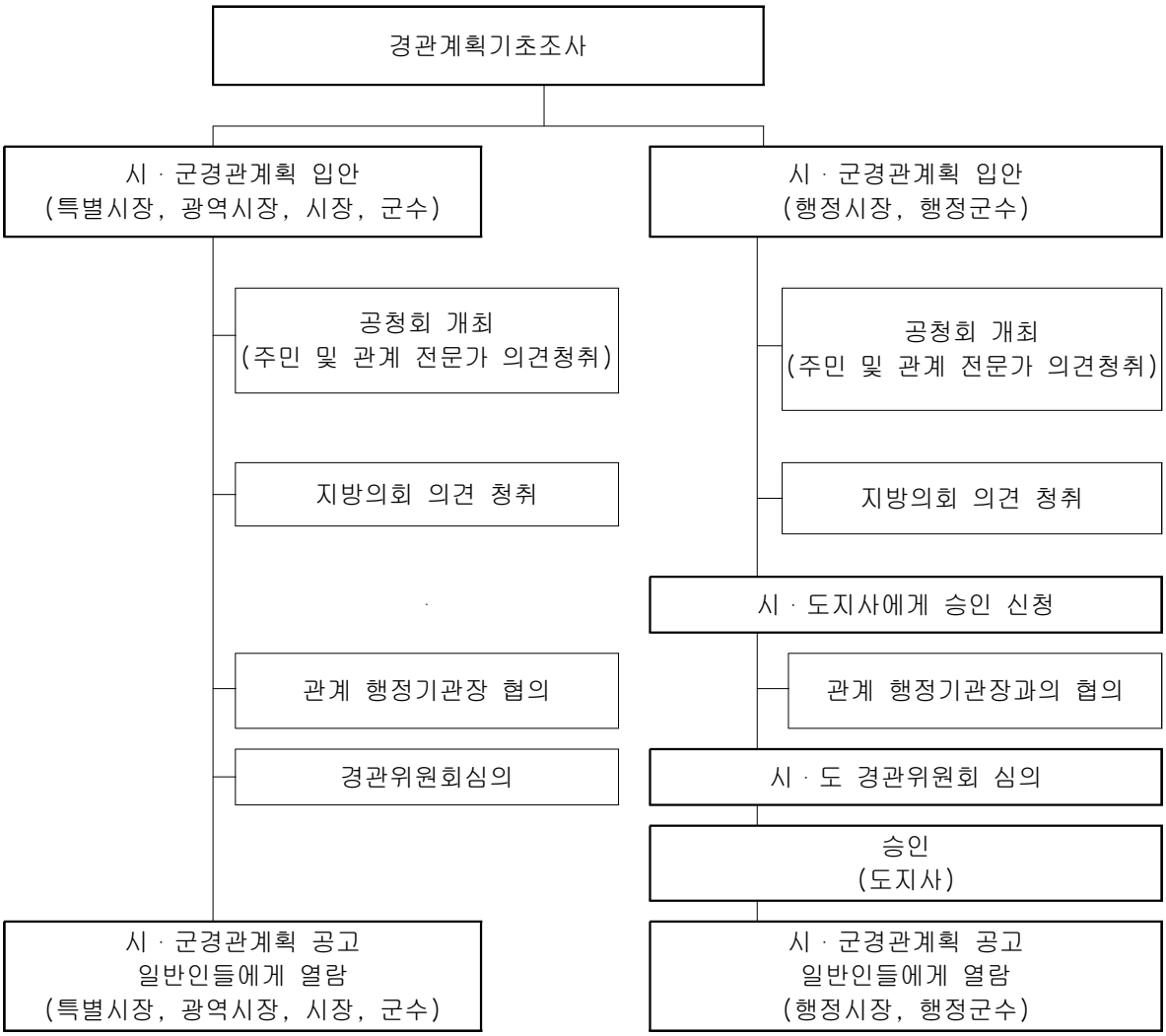

1-4 품 산정의 원단위 산정과 기준

1-4-1 표준품 산정내역

○ 표준품 산정의 기준이 되는 비목은 제1장 총칙에서 제시한 비목을 중심으로 하였으며, 이는 경관계획수립에 필요한 사항만을 대상으로 한다.

○ 표준품책정의 기본이 되는 직접인건비 품의 작업항목별 보할은 항목별 업무의 난이도를 감안하여 설정토록 한다.

1. 시·군 경관계획

○ 시·군 경관계획은 경관계획과 특정경관계획으로 구분될 수 있으며, 본 품셈은 기본경관계획수립을 기준으로 책정한다.

○ 특정한 지역에 대하여 특정경관계획을 수립하는 경우, 2절 지구경관계획의 경관상세계획을 준용하여 비용을 책정한다.

○ 특정한 경관유형이나 경관요소에 대한 특정경관계획을 수립하는 경우, 기본경관계획 품셈기준의 70% 이상으로 준용하여 책정한다.

○ 경관법 제15조에 따라 시·군 경관계획을 재정비 하는 경우, 시·군 경관계획 품셈기준의 70% 이상으로 준용하여 책정한다.

종 별		내 용	단 위	비 고
직접비	직접인건비	1. 경관현황 조사·분석 2. 도시경관 구상 3. 경관기본 계획 4. 경관 가이드라인 5. 실행계획 6. 성과품 작성 7. 기술협의	인·일 〃 〃 〃 〃 〃 〃	
	직접경비	여비, 인쇄비, 조감도, 회의준비비, 현장운영비 등	식	제1장 총칙참조
간접비	제경비	(직접인건비)×120%	〃	〃
	기술료	(직접인건비+제경비) ×30%	〃	〃

주 : ①시 · 군경관계획 수립후의 경관시행사업 또는 경관상세계획에 해당하는 구체적인 경관디자인 등의 제시는 별도의 직접경비로 책정한다.

②중점경관관리구역 등을 토지이용계획 확인원에 탑재하기 위한 결정조서와 도면을 작성하여 KLIS에 등록하는 경우, 제2장 도시계획 중 제5절 지형도면고시계획품셈기준을 적용하여 비용을 별도로 책정한다.

2. 도시 · 군경관부문계획

종 별		내 용	단 위	비 고
직접비	직접인건비	1.경관현황분석 2.기본구상 3.경관계획 4.실행계획 5.성과품 작성 6.기술협의	인·일 〃 〃 〃 〃 〃	
	직접경비	여비, 인쇄비, 조감도, 회의준비비, 현장운영비 등	식	제1장 총칙참조
간접비	제경비	(직접인건비)×120%	〃	〃
	기술료	(직접인건비+제경비) ×30%	〃	〃

1-4-2 산정기준

1. 계획·기준인구의 설정

○ 경관계획수립을 위한 기준인구는 전국적으로 대상이 되는 시의 인구분포를 분석하여 인구 30만인으로 설정하며, 최소인구는 10만인으로 적용한다.

○ 직능별 직접인력 소요원단위는 기 작성된 도시경관계획 등의 투입기술자 비율을 감안하여 설정한다.

○ 계획인구는 당해 도시권의 목표인구를 원칙으로 한다.

2. 표준품의 산정방법

○ 표준품의 적용에 있어 기준인구(면적)와 계획인구(면적)의 차이에 따른 품 산정은 아래의 수정식에 따라 기준인구(면적)의 소요작업량을 수정하여 산정한다.

1) 시·군경관계획

○ 소요작업량 = 기준인구 소요작업량 × 인구보정계수(α) × 면적보정계수(β)

2) 도시·군경관부문계획

○ 소요작업량 = 기준인구 소요작업량×인구보정계수(α)×면적보정계수(β)×난이도보정계수(γ)

3. 계획안의 수정과 과업중지에 따른 품 산정방법

○ 계획안이 작성되고 주민공람, 의회보고 등 기술협의과정을 거쳐 계획안이 확정된 후 발주자의 사정에 의하여 계획안이 일부변경 · 재작업이 수행되는 경우에는 그 변경·재작업의 정도에 따라 엔지니어링사업대가의 50~100% 이상 수준에서 비용을 추가 지급하여야 한다.

○ 과업수행 중 발주자의 사정에 따른 과업 중단으로 인해 정부 회계연도가 경과되어 현저한 비용의 차이가 발생하였을 경우에는 엔지니어링사업대가를 당해 신년도의 노임단가를 기준으로 재산정하여야 한다.

1-4-3 단위별 변화수정과 보정

1. 인구의 대소에 대한 작업량 보정계수 산정

○ 도시의 계획인구가 기준인구를 초과하거나 못 미치는 경우의 직접인력 소요작업량의 산정을 위한 보정계수는 다음의 식에 의해 산정한다.

$$\alpha = \left(\frac{\text{계획인구}}{\text{기준인구}}\right)^{0.6} = \left(\frac{A}{30}\right)^{0.6}$$

α = 보정계수, A = 계획인구(만인)

계획단위 인구별 보정계수

계획인구(만인)	보정계수 (α)	계획인구(만인)	보정계수 (α)
10	0.517	100	2.059
15	0.659	120	2.297
20	0.784	150	2.626
30	1.000	200	3.121
50	1.358	400	4.731
70	1.662	500	5.408

주 : 계획인구가 10만인 미만인 경우에는 계획인구 10만인을 기준으로 하여 산정하며, 면적 보정계수를 적용하여 책정한다.

2. 면적의 대소에 대한 작업량 보정계수 산정

○ 시·군의 계획인구가 10만 이하인 경우, 계획면적에 따라 다음의 보정계수를 적용한다.

면적 규모에 따른 보정계수

구 분	난이도 보정계수(β)
1.면적이 400㎢ 미만인 지역	1.00
2.면적이 400㎢ 이상~600㎢ 미만인 지역	1.25
3.면적이 600㎢ 이상인 지역	1.50

3. 계획성격에 따른 난이도 보정계수 산정

○ 도시·군경관부문계획 수립 시, 경관법에 의한 별도의 경관계획이 수립되지 않은 지역은 난이도(γ)를 보정하여 별도의 경관계획에 준하는 계획이 수립될 수 있는 여건을 마련한다.

경관계획수립 여부에 따른 난이도 보정계수

구 분	보정계수(γ)
1.경관법에 의한 경관계획을 수립한 지역	1.0
2.경관법에 의한 경관계획을 수립하지 않은 지역	2.0

1-5 표준단위 업무분류와 원단위

1-5-1 시·군경관계획

기술업무의 직능별 직접인력 소요작업량 (인구 30만인 기준)

(단위 : 인·일/표준단위)

구 분	업무내용	표준단위	소요인력						비고
			기술사	특 급	고 급	중 급	초 급	보조원	
1.경관현황 조사·분석	①경관자원조사	30만인	2.0	3.0	6.0	12.6	16.8	22.8	
	②경관구조분석	30만인	0.8	1.2	2.4	2.1	2.8	3.8	
	③경관의식조사	30만인	0.4	0.6	1.2	2.1	2.8	3.8	
	④관련법규및관련계획/유사사례검토	30만인	0.4	0.6	1.2	2.1	2.8	3.8	
	⑤종합분석	30만인	0.8	1.2	2.4	3.1	4.5	5.4	
	소 계		4.4	6.6	13.2	22.0	29.7	39.6	
2.도시경관 구상	①기본방향설정	30만인	0.8	1.1	1.6	2.7	5.5	8.2	
	②미래상 설정	30만인	0.8	1.1	1.6	2.7	5.5	8.2	
	③추진전략 설정	30만인	0.8	1.1	1.6	2.7	5.5	8.2	
	④경관구조 설정	30만인	0.9	1.1	1.8	2.9	5.5	8.4	
	소 계		3.3	4.4	6.6	11.0	22.0	33.0	
3.경관기본 계획	①경관권역계획	30만인	6.6	13.2	33.0	36.2	39.6	39.6	
	②경관축계획	30만인	4.4	8.8	22.0	24.3	26.4	26.4	
	③경관거점계획	30만인	3.3	6.6	16.5	18.1	19.8	19.8	
	④중점경관관리구역계획	30만인	4.4	8.8	22.0	24.3	26.4	26.4	
	⑤경관지구 및 미관지구 계획	30만인	3.3	6.6	16.5	18.1	19.8	19.8	
	소 계		22.0	44.0	110.0	121.0	132.0	132.0	
4.경관가이드라인	①경관권역 등의 가이드라인	30만인	1.1	2.1	4.2	6.6	8.8	10.2	
	②경관·미관지구의 경관가이드라인	30만인	0.9	1.9	3.9	6.2	8.2	9.4	
	③중점경관관리구역의 경관가이드라인	30만인	3.5	7.0	13.9	21.3	28.5	32.8	
	소 계		5.5	11.0	22.0	34.1	45.5	52.4	
5.실행계획	①경관관련 지역, 지구 및 구역 등의 적용 및 연계방안	30만인	0.3	0.4	0.9	1.7	2.2	3.2	
	②지구단위계획 등 관련 계획과의 연계방안	30만인	0.3	0.4	0.9	1.7	2.2	3.2	
	③경관사업 및 단계별 추진계획에 관한 사항	30만인	1.8	2.4	5.4	9.1	12.1	17.0	
	④경관협정의 적용 및 운영에 관한 사항	30만인	0.3	0.4	0.9	1.7	2.2	3.2	
	⑤경관관리 실행조직 및 실행체계에 관한 사항	30만인	0.3	0.4	0.9	1.7	2.2	3.2	
	⑥경관조례 및 경관관련 자문 및 심의에 관한 사항	30만인	0.3	0.4	0.9	1.7	2.2	3.2	
	소 계		3.3	4.4	9.9	17.6	23.1	33.0	
6.성과품 작성	①보고서작성 및 편집	30만인	1.8	2.9	6.7	11.5	14.4	14.4	
	②관련도서작성	30만인	0.4	0.4	1.0	1.7	2.1	2.1	
	소 계		2.2	3.3	7.7	13.2	16.5	16.5	
총 계			40.7	73.7	169.4	218.9	268.8	306.5	
7.기술협의	①공청회/주민설명회	1식	2.0	2.0	2.0	4.0	4.0	4.0	주1
	②주민간담회/시민계획단	1식	2.0	2.0	2.0	4.0	4.0	4.0	
	③위원회심의 지원	1식	2.0	2.0	2.0	4.0	4.0	4.0	
	④관계기관 협의	1식	2.0	2.0	2.0	4.0	4.0	4.0	
	소 계		8.0	8.0	8.0	16.0	16.0	16.0	

주 : ①기술협의는 2회 이내 기준이며, 횟수가 늘어날 경우 증가배수에 해당하는 작업품과 비용을 가산한다. (필요항목 선택적 적용)

②경관시행사업 또는 경관상세계획에 해당하는 구체적인 경관디자인 등의 제시는 별도의 직접경비로 산정한다

1-5-2 도시·군경관부문계획

기술업무의 직능별 직접인력 소요작업량 (인구 30만인 기준)

(단위 : 인·일/표준단위)

구 분	업무내용	표준단위	소요인력						비고
			기술사	특 급	고 급	중 급	초 급	보조원	
1.경관현황 분석	①현황조사	30만인	0.4	0.6	1.4	4.3	5.7	7.4	
	②관련법규 · 계획 검토	30만인	0.2	0.3	0.7	1.1	1.5	2.1	
	③현황종합분석	30만인	0.9	1.4	2.5	2.2	3.0	4.2	
	소 계		1.5	2.3	4.6	7.6	10.2	13.7	
2.기본구상	①도시미래상 설정	30만인	0.3	0.5	0.7	1.1	2.3	3.4	
	②경관구조설정	30만인	0.3	0.5	0.7	1.1	2.3	3.4	
	③경관형성전략	30만인	0.5	0.5	0.9	1.6	3.0	4.6	
	소 계		1.1	1.5	2.3	3.8	7.6	11.4	
3.경관계획	①경관권역계획	30만인	1.6	3.0	7.6	8.1	8.9	9.8	
	②경관축계획	30만인	0.8	1.5	3.8	4.1	4.5	4.9	
	③경관거점계획	30만인	0.8	1.5	3.8	4.1	4.5	4.9	
	④경관중점관리구역계획	30만인	2.8	6.2	15.2	15.9	17.5	19.2	
	⑤경관지구 및 미관지구 계획	30만인	1.6	3.0	7.6	8.1	8.9	9.8	
	소 계		7.6	15.2	38	40.3	44.3	48.6	
4.실행계획	①경관가이드라인	30만인	0.6	1.1	2.3	4.2	4.6	5.0	
	②실행방안	30만인	1.3	2.7	5.3	9.7	10.6	11.7	
	소 계		1.9	3.8	7.6	13.9	15.2	16.7	
5.성과품 작성	①보고서 작성 및 편집	30만인	0.4	0.6	1.4	2.4	2.6	2.9	
	②관련 도서 작성	30만인	0.4	0.5	1.3	2.3	2.5	2.8	
	소 계		0.8	1.1	2.7	4.7	5.1	5.7	
총 계			12.9	23.9	55.2	70.3	82.4	96.1	
6.기술협의	①공청회/주민설명회	1식	2.0	2.0	2.0	4.0	4.0	4.0	주1
	②주민간담회/시민계획단	1식	2.0	2.0	2.0	4.0	4.0	4.0	
	③위원회심의 지원	1식	2.0	2.0	2.0	4.0	4.0	4.0	
	④관계기관 협의	1식	2.0	2.0	2.0	4.0	4.0	4.0	
	소 계		8.0	8.0	8.0	16.0	16.0	16.0	

주 : ①기술협의는 2회 이내 기준이며, 횟수가 늘어날 경우 증가배수에 해당하는 작업품과 비용을 가산한다. (필요항목 선택적 적용)

②도시·군관리계획업무내용 중 경관부문계획에 적용하며, 도시·군관리계획 수립에 따른 경관검토서는 제8장 도시평가의 경관성검토를 준용하여 비용을 책정한다.

1-6 주요업무내용

1-6-1 시·군경관계획

구 분	내 용
1.경관현황조사·분석	·경관자원조사 ·경관구조분석 ·경관의식조사 ·관련 법규 및 유사사례 검토 ·종합분석
2.도시경관구상	·기본방향 및 미래상 설정 ·경관구조 설정
3.경관기본계획	·경관권역, 축, 거점계획 ·중점경관관리구역 계획 ·경관지구 및 미관지구 계획
4.경관가이드라인	·경관권역 등 가이드라인 ·중점경관관리구역 가이드라인 ·경관·미관지구 가이드라인
5.실행계획	·경관관련 지역, 지구 및 구역 등의 적용 및 연계방안 ·지구단위계획 등 관련 계획과의 연계방안 ·경관사업 및 단계별 추진 등에 관한 사항 ·경관협정의 적용 및 운영에 관한 사항 ·경관관리 실행조직 및 실행체계에 관한 사항 ·경관조례 및 경관관련 자문 및 심의에 관한 사항

1-6-2 도시·군 경관부문계획

구 분	내 용
1.경관현황분석	·현황조사 ·관련법규 · 계획 검토 ·현황종합분석
2.기본구상	·도시미래상 설정 ·경관구조설정 ·경관형성전략
3.경관계획	·권역, 축, 거점계획 ·경관관리대상지역계획
4.실행계획	·경관가이드라인 ·실행방안

1-7 표준성과품

1-7-1 시·군경관계획

성과구분	표준성과도서			비 고
	구 분	규 격	제출부수	
보고서	·경관계획보고서	A4		발주자와 협의
각종도면	·경관기본구상도	A3	1식	
	·경관계획도	A3	1식	
	·경관지침도	A3		발주자와 협의

주 : ①제출부수 및 성과품 종류가 증가할 경우에는 증가배수에 해당하는 작업품과 비용을 가산한다.
②심의도서 및 기타 관련 자료의 규격 및 제출부수는 발주자와의 협의에 의하여 비용을 산정한다.
③도면의 축척은 발주자와의 협의를 통하여 계획의 내용을 표현하기에 적당한 축적 수준을 선택한다

1-7-2 도시·군 경관부문계획

성과구분	표준성과도서			비 고
	구 분	규 격	제출부수	
보고서	·경관(부문)계획보고서	A4		발주자와 협의
각종도면	·경관관리구상도	1/5,000~1/25,000	1식	

주 : ①제출부수 및 성과품 종류가 증가할 경우에는 증가배수에 해당하는 작업품과 비용을 가산한다.
②도면의 축척은 발주자와의 협의를 통하여 계획의 내용을 표현하기에 적당한 축적 수준을 선택한다

제2절 지구경관계획

2-1 정 의

○ 지구경관계획은 개발사업경관계획(사전경관계획 비수립), 개발사업경관계획(사전경관계획 수립), 경관상세계획, 농·산·어촌경관계획, 경관기본설계로 구분하여 경관품셈기준을 책정한다.

2-1-1 개발사업경관계획

○ 개발사업경관계획 품셈기준은 「경관법」제27조와 「경관법 시행령」제19조에 따른 개발사업에 대한 경관계획 수립 시 적용한다.

○ 「경관법」제27조와 「경관법 시행령」제20조에 따라 사전경관계획을 수립하도록 되어 있는 개발사업 대상지역의 면적이 30만㎡이상이거나 개발사업으로 건축되는 건축물 연면적의 합계가 20만㎡ 이상인 개발사업은 개발사업경관계획(사전경관계획 수립)의 품셈기준을 적용하여 비용을 책정한다.

○ 사전경관계획을 수립해야 하는 규모 이외의 개발사업의 경관계획은 개발사업경관계획(사전경관계획 비수립)의 품셈기준을 적용하여 비용을 책정한다.

2-1-2 경관상세계획

○ 경관상세계획 품셈기준은 실시계획 단계에서 수립하는 경관부문계획을 대상으로 하며 「국토의 계획 및 이용에 관한 법률」에 따라 지구단위계획 중 부문계획으로 수립하는 경관계획 수립 시 적용한다.

○ 「경관법」제27조와 「경관법 시행령」제19조에 해당하는 개발사업으로 경관심의를 득한 개발사업 중 경관계획 성과품과 그래픽 관련 원본자료를 인계받는 경우, 경관상세계획 품셈기준의 50% ~ 70%를 적용하여 비용을 책정할 수 있다.

2-1-3 농 · 산 · 어촌경관계획

○ 농·산·어촌경관계획 품셈기준은 농·산·어촌에 대한 지역개발이나 생활환경정비사업 시, 경관부문계획에 적용하며 대상지는 농지, 산지, 해안 등을 포함한다.

2-1-4 경관기본설계

○ 경관기본설계 품셈기준은 기본설계 단계에서 수립하는 경관계획을 대상으로 하며, 각종 개발사업이나 「경관법」에 따른 경관사업 등의 경관기본설계 시 적용한다.

○ 지방자치단체 또는 경관협정에 의해 시행하는 경관개선 및 경관형성을 위한 사업에 대하여 실시설계 이전 단계로 수립하는 경관설계 시 적용하며, 퍼실리테이션 단계 또는 기본설계 이전 단계의 별도의 경관계획을 수립하는 경우 지역 특성에 따라 경관상세계획이나 농·산·어촌경관계획의 품셈기준을 준용하여 책정한다.

○ 각종 개발사업에 따른 일단의 대지 조성 시 공공영역의 포장 및 시설물에 대한 별도의 경관계획을 수립하는 경우 적용할 수 있다.

지구경관계획의 체계

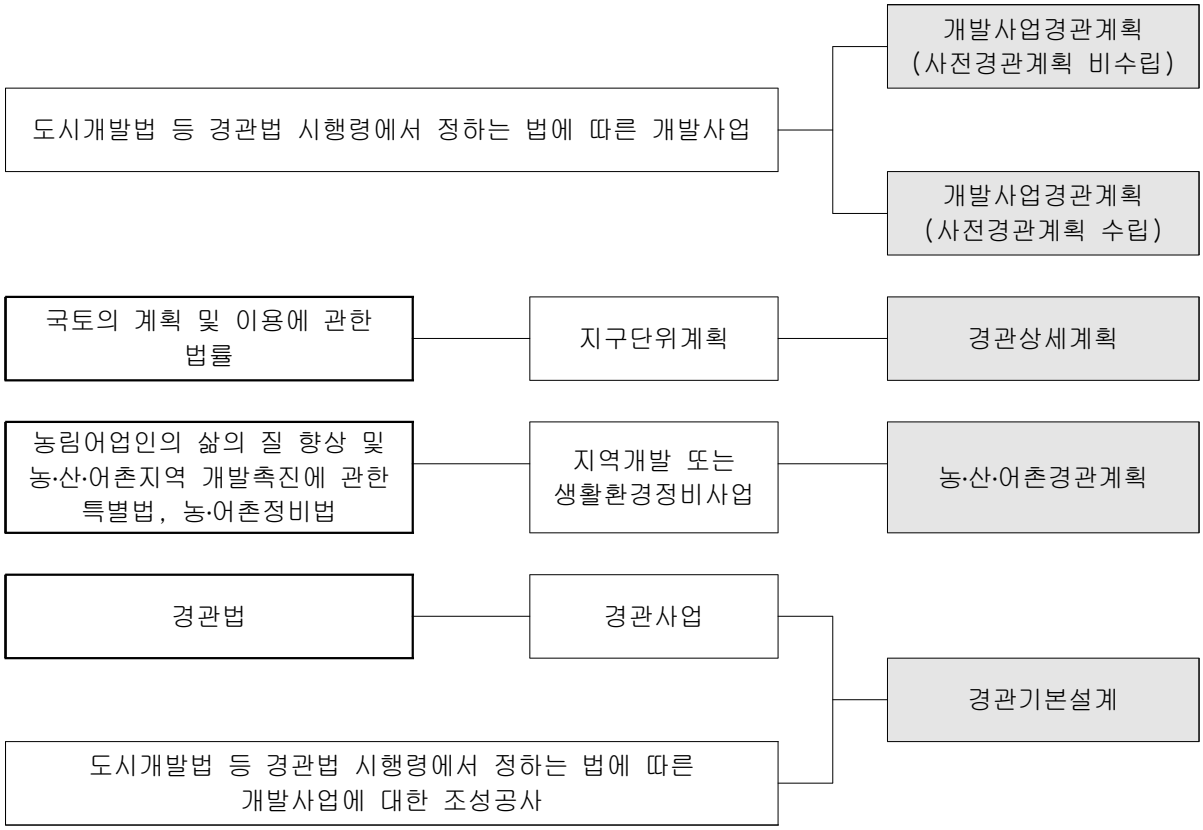

2-2 자료제공의 전제

○ 당해 계획의 수립에 필요한 모든 관련 자료는 원칙적으로 발주자가 제공하는 것으로 하되, 발주자가 보유하지 않은 자료는 엔지니어링사업자가 수집한다.

○ 발주자가 제공하지 못하는 자료의 조사에는 그 규모·내용에 의거하여 별도의 엔지니어링사업대가를 산정하여 엔지니어링사업자가 수행하며, 당해 관련 자료의 보안이나 광범위한 자료가 요구될 경우는 조사 분석에 필요한 기간과 자료수집비용이 전제되어야 한다.

2-3 업무범위와 추진과정

2-3-1 업무범위

○ 개발사업경관계획(사전경관계획 비수립), 개발사업경관계획(사전경관계획 수립)은 경관심의운영지침과 사전경관계획 매뉴얼을 준용하여 작성한다.

○ 경관상세계획은 경관계획수립지침의 특정경관계획과 지구단위계획수립지침의 경관부문을 준용하여 작성하며, 심의(자문)도서는 심의주체기관의 별도 매뉴얼이 없는 경우 경관심의운영지침을 준용하여 작성한다.

○ 농·산·어촌경관계획은 농·어촌경관계획 수립요령, 농·어촌경관 관리·활용 매뉴얼을 준용하여 작성한다.

○ 경관기본설계는 별도의 기준이 없는 경우, 사업의 성격에 따라 경관심의운영지침의 사회기반시설사업의 경관심의를 준용하며 현황분석, 경관구상, 실행계획, 경관기본설계, 유지 및 관리방안 제시 순으로 작성한다.

2-3-2 추진과정

○ 관계법과 지침에 따라 절차를 이행하며 관계기관과의 협의, 전문가 자문, 심의 등에 소요되는 기간은 과업수행기간에서 제외하여 그 소요기간 만큼 과업수행기간을 연장하여야 한다.

개발사업 경관심의 추진과정

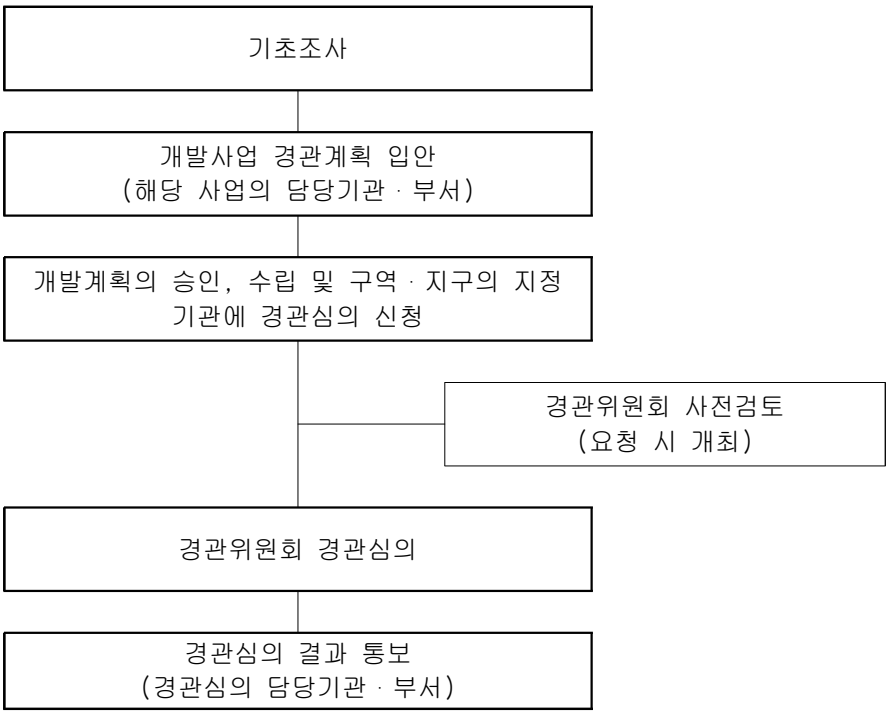

2-4 품 산정의 원단위 산정과 기준

2-4-1 표준품 산정내역

○ 표준품 산정의 기준이 되는 비목은 제1장 총칙에서 제시한 비목을 중심으로 하였으며, 이는 경관계획수립에 필요한 사항만을 대상으로 한다.

○ 표준품 산정의 기본이 되는 직접인건비 품의 작업항목별 보할은 기존의 경험적 내용 및 항목별 업무의 난이도를 감안하여 설정토록 한다.

1. 개발사업 경관계획 (사전경관계획 비수립)

종 별		내 용	단 위	비 고
직접비	직접인건비	1.현황조사 및 분석 2.기본방향 및 목표 3.경관기본구상 4.경관 부문별 계획 5.성과품 작성 6.기술협의	인·일 〃 〃 〃 〃 〃	
	직접경비	여비, 인쇄비, 조감도, 회의준비비, 현장 운영비 등	식	제1장 총칙참조
간접비	제경비	(직접인건비)×120%	〃	〃
	기술료	(직접인건비+제경비) ×30%	〃	〃

주 : ①경관계획 수립후의 경관시행사업 또는 경관상세계획에 해당하는 구체적인 경관디자인 등의 제시는 별도의 직접경비로 산정한다.

2. 개발사업 경관계획 (사전경관계획 수립)

종 별		내 용	단 위	비 고
직접비	직접인건비	1.경관현황분석 2.기본방향 및 목표 3.경관구조 설정 4.입체적 도시 공간구조 기본구상 5.종합계획 및 통합지침도 작성 6.성과품 작성 7.기술협의	인·일 〃 〃 〃 〃 〃 〃	
	직접경비	여비, 인쇄비, 조감도, 회의준비비, 현장 운영비 등	식	제1장 총칙참조
간접비	제경비	(직접인건비)×120%	〃	〃
	기술료	(직접인건비+제경비) ×30%	〃	〃

주 : ①경관계획 수립후의 경관시행사업 또는 경관상세계획에 해당하는 구체적인 경관디자인 등의 제시는 별도의 직접경비로 산정한다.

3. 경관상세계획

종 별		내 용	단 위	비 고
직접비	직접인건비	1.경관현황조사·분석 2.지구경관구상 3.부문별 경관계획 4.경관지침 5.경관시뮬레이션구상 6.성과품작성 7.기술협의	인·일 〃 〃 〃 〃 〃 〃	
	직접경비	여비, 인쇄비, 조감도, 회의준비비, 현장 운영비 등	식	제1장 총칙참조
간접비	제경비	(직접인건비)×120%	〃	〃
	기술료	(직접인건비+제경비) ×30%	〃	〃

주 : ①경관계획 수립후의 경관시행사업 또는 경관기본설계에 해당하는 구체적인 경관디자인 등의 제시는 별도의 직접경비로 산정한다.

4. 농·산·어촌경관계획

종 별		내 용	단 위	비 고
직접비	직접인건비	1.경관현황분석 2.경관구상 3.부문별 경관계획 4.실행계획 5.성과품 작성 6.기술협의	인·일 〃 〃 〃 〃 〃	
	직접경비	여비, 인쇄비, 조감도, 회의준비비, 현장 운영비 등	식	제1장 총칙참조
간접비	제경비	(직접인건비)×120%	〃	〃
	기술료	(직접인건비+제경비) ×30%	〃	〃

주 : ①경관계획 수립후의 경관시행사업 또는 경관기본설계에 해당하는 구체적인 경관디자인 등의 제시는 별도의 직접경비로 산정한다.

5. 경관기본설계

종 별		내 용	단 위	비 고
직접비	직접인건비	1.경관현황분석 2.경관구상 3.실행계획 4.경관기본설계 5.유지 및 관리방안 제시 6.성과품 작성 7.기술협의	인·일 〃 〃 〃 〃 〃 〃	
	직접경비	여비, 인쇄비, 조감도, 회의준비비, 현장 운영비 등	식	제1장 총칙참조
간접비	제경비	(직접인건비)×120%	〃	〃
	기술료	(직접인건비+제경비) ×30%	〃	〃

주 : ①경관실시설계에 해당하는 내용은 포함하지 않으며 별도의 직접경비로 산정한다.

2-4-2 산정기준

1. 계획·기준면적의 설정

○ 경관계획수립을 위한 기준면적은 대상지의 특성에 맞도록 설정하였으며, 관계법에 따른 기준 면적이나 관련 계획에서 사용하는 기준면적을 따른다.

1) 개발사업경관계획 (사전경관계획 비수립)

○ 대상지 면적이 30만㎡ 미만의 개발사업을 고려하여 기준면적을 10만㎡로 하고, 도시지역의 개발사업 시 경관심의 대상 기준 면적인 3만㎡(경관법 시행령 제19조)를 최소면적으로 한다.

2) 개발사업경관계획 (사전경관계획 수립)

○ 사전경관계획을 수립해야하는 기준 면적인 30만㎡(경관법 시행령 제20조)를 기준면적으로 하고, 최소면적도 동일하게 적용한다.

3) 경관상세계획

○ 유사한 계획성격을 지닌 개발사업경관계획의 기준면적을 고려하여 기준면적을 20만㎡로 하고, 3만㎡를 최소면적으로 적용한다.

4) 농·산·어촌경관계획

○ 농·산·어촌경관계획 수립 대가기준의 기준면적과 최소면적을 준용하여 150만㎡를 기준면적으로 하고, 최소면적은 40만㎡로 한다.

5) 경관기본설계

○ 도시 및 주거환경 정비계획 중 가로주택 정비사업의 기준면적을 준용하여 기준면적 1만㎡, 최소면적 5,000㎡를 적용하며 면적 기준을 적용하기 어려운 경우 거리기준을 적용하며 기준거리 1km, 최소거리 0.5km로 한다.

2. 표준품의 산정방법

○ 표준품의 적용에 있어 기준인구(면적)와 계획인구(면적)의 차이에 따른 품 산정은 아래의 수정식에 따라 기준인구(면적)의 소요작업량을 수정하여 산정한다.

1) 개발사업경관계획 (사전경관계획 비수립)

○ 소요작업량 = 기준면적 소요작업량 × 면적보정계수(α) × 난이도보정계수(β)

2) 개발사업경관계획 (사전경관계획 수립)

○ 소요작업량 = 기준면적 소요작업량 × 면적보정계수(α) × 난이도보정계수(β)

3) 경관상세계획

○ 소요작업량 = 기준면적 소요작업량 × 면적보정계수(α) × 난이도보정계수(β)

4) 농·산·어촌경관계획

○ 소요작업량 = 기준면적 소요작업량 × 면적보정계수(α)

5) 경관기본설계

○ 소요작업량 = 기준면적 소요작업량 × 면적보정계수(α) × 난이도보정계수(β)

3. 계획안의 수정과 과업중지에 따른 품 산정방법

○ 계획안이 작성되고 자문이나 심의 등 기술협의과정을 거쳐 계획안이 확정된 후 발주자의 사정에 의하여 계획안이 일부변경 · 재작업이 수행되는 경우에는 그 변경·재작업의 정도에 따라 엔지니어링사업대가의 50~100% 이상 수준에서 비용을 추가 지급하여야 한다.

○ 과업수행 중 발주자의 사정에 따른 과업 중단으로 인해 정부 회계연도가 경과되어 현저한 비용의 차이가 발생하였을 경우에는 엔지니어링사업대가를 당해 신년도의 노임단가를 기준으로 재산정하여야 한다.

2-4-3 단위별 변화수정과 보정

1. 면적의 대소에 대한 작업량 보정계수 산정

○ 지구경관계획의 계획면적이 기준 면적을 초과하거나 못 미치는 경우의 직접인력 소요작업량의 산정을 위한 보정계수는 다음의 식에 의해 산정한다.

1) 개발사업경관계획 (사전경관계획 비수립)

$$\alpha_1 = \left(\frac{\text{계획면적}}{\text{기준면적}}\right)^{0.6} = \left(\frac{A}{10}\right)^{0.6}$$

α_1 = 보정계수, A = 계획면적(만㎡)

계획단위 면적별 보정계수

계획면적(만㎡)	보정계수 (α_1)	계획면적(만㎡)	보정계수 (α_1)
3	0.485	20	1.516
5	0.659	30	1.933
7	0.807	50	2.627
10	1.000	100	3.981
15	1.275	200	6.034

주 : 계획면적이 3만㎡ 미만인 경우에는 계획면적 3만㎡를 기준으로 하여 산정한다.

2) 개발사업경관계획 (사전경관계획 수립)

$$\alpha_2 = (\frac{\text{계획면적}}{\text{기준면적}})^{0.6} = (\frac{A}{30})^{0.6}$$

α_2 = 보정계수, A = 계획면적(만㎡)

계획단위 면적별 보정계수

계획면적(만㎡)	보정계수(α_2)	계획면적(만㎡)	보정계수(α_2)
30.0	1.000	90.0	1.933
40.0	1.188	100.0	2.059
50.0	1.358	150.0	2.626
60.0	1.515	200.0	3.121
70.0	1.662	300.0	3.981

주 : 계획면적이 30만㎡ 미만인 경우에는 계획면적 30만㎡를 기준으로 하여 산정한다.

3) 경관상세계획

$$\alpha_3 = (\frac{\text{계획면적}}{\text{기준면적}})^{0.6} = (\frac{A}{20})^{0.6}$$

α_3 = 보정계수, A = 계획면적(만㎡)

계획단위 면적별 보정계수

계획면적(만㎡)	보정계수 (α_3)	계획면적(만㎡)	보정계수 (α_3)
3.0	0.320	70.0	2.120
5.0	0.435	100.0	2.626
10.0	0.659	150.0	3.349
20.0	1.000	200.0	3.981
30.0	1.275	300.0	5.077
50.0	1.732		

주 : 계획면적이 3만㎡ 미만인 경우에는 계획면적 3만㎡를 기준으로 하여 산정한다.

4) 농·산·어촌경관계획

$$\alpha_4 = (\frac{\text{계획면적}}{\text{기준면적}})^{0.6} = (\frac{A}{150})^{0.6}$$

α_4 = 보정계수, A = 계획면적(만㎡)

계획단위 면적별 보정계수

계획면적(만㎡)	보정계수 (α_4)	계획면적(만㎡)	보정계수 (α_4)
40.0	0.452	100.0	0.784
60.0	0.577	150.0	1.000
70.0	0.633	200.0	1.188
80.0	0.685	300.0	1.515
90.0	0.736	330.0	1.604

주 : 계획면적이 40만㎡ 미만인 경우에는 계획면적 40만㎡를 기준으로 하여 산정한다.

5) 경관기본설계

$$\alpha_5 = (\frac{\text{계획면적(거리)}}{\text{기준면적(거리)}})^{0.6} = (\frac{A}{1})^{0.6}$$

α_5 = 보정계수, A = 계획면적(만㎡), 계획거리(㎞)

계획단위 면적별 보정계수

계획면적(만㎡) 계획거리(㎞)	보정계수 (α_5)	계획면적(만㎡) 계획거리(㎞)	보정계수 (α_5)
0.5	0.659	20	6.034
1	1.000	50	10.456
2	1.515	70	12.795
5	2.626	100	15.848
10	3.981	200	24.022

주 : 계획면적이 0.5만㎡ 미만인 경우에는 계획면적 0.5만㎡를 기준으로 하여 산정한다. 계획거리가 0.5㎞ 미만인 경우에는 계획거리 0.5㎞를 기준으로 하여 산정한다.

2. 계획업성격에 따른 난이도 보정계수 산정

○ 사업 대상지와 계획의 특성(밀도)에 따라 난이도 보정계수를 적용하여 산정한다.

1) 개발사업경관계획(사전경관계획 비수립), 개발사업경관계획(사전경관계획 수립)

지구밀도변화에 따른 보정계수

구 분	지구밀도 보정계수(β_1)
1. 비도시지역형 : 비도시지역을 대상으로 하는 단일유형의 개발사업	1.00
2. 도시지역형 : 상업지역을 제외한 도시지역의 개발이나 복합유형의 개발사업	1.50
3. 도심지역형: 상업지역, 준주거지역에 대한 개발사업	2.00

2) 경관상세계획

지구밀도변화에 따른 보정계수

구 분	지구밀도 보정계수(β_2)
1. 비도시지역형 : 비도시지역을 대상으로 하는 단일유형의 개발사업	1.00
2. 도시지역형 : 상업지역을 제외한 도시지역의 개발이나 복합유형의 개발사업	1.50
3. 도심지역형 : 상업지역, 준주거지역에 대한 개발사업	2.00
4. 특수형 : 별도의 경관상세계획 수립 또는 별도의 요소별 경관계획 수립 시	3.00

3) 경관기본설계

입체구조물 포함여부에 따른 보정계수

구 분	지구밀도 보정계수(β_3)
1. 일반형 : 고가구조물, 지하구조물, 터널, 교량 등의 입체구조물 불포함	1.00
2. 입체형 : 고가구조물, 지하구조물, 터널, 교량 등의 입체구조물 포함	1.75

2-5 표준단위 업무분류와 원단위

2-5-1 개발사업경관계획 (사전경관계획 비수립)

기술업무의 직능별 직접인력 소요작업량 (면적 10만㎡ 기준)

(단위 : 인·일/표준단위)

구 분	업무내용	표준단위	소요인력						비고
			기술사	특 급	고 급	중 급	초 급	보조원	
1.현황조사 및 분석	①경관자원 및 특성	10만㎡	0.1	0.2	0.6	1.2	1.8	2.2	
	②관련 법규 및 계획	10만㎡	0.1	0.2	0.4	0.4	0.6	0.8	
	③경관 종합분석	10만㎡	0.2	0.2	0.3	0.4	0.6	0.8	
	소 계		0.4	0.6	1.3	2.0	3.0	3.8	
2.기본방향 및 목표	①기본방향 및 목표 설정	10만㎡	0.2	0.2	0.4	0.7	0.9	1.3	
	②경관형성전략 수립	10만㎡	0.1	0.2	0.4	0.6	0.9	1.2	
	소 계		0.3	0.4	0.8	1.3	1.8	2.5	
3.경관기본 구상	①경관구조 설정	10만㎡	0.1	0.2	0.4	0.6	0.9	1.3	
	②경관권역 기본구상	10만㎡	0.2	0.2	0.4	0.8	1.1	1.4	
	③경관축 기본구상	10만㎡	0.1	0.2	0.4	0.7	0.9	1.4	
	④경관거점 기본구상	10만㎡	0.1	0.2	0.4	0.7	0.9	1.4	
	소 계		0.5	0.8	1.6	2.8	3.8	5.5	
4.경관부문별 계획	①건축물 경관계획	10만㎡	1.1	2.3	5.5	5.7	6.3	6.9	
	②가로경관계획	10만㎡	1.1	2.3	5.5	5.7	6.3	6.9	
	③공원 및 녹지 경관계획	10만㎡	1.1	2.3	5.5	5.7	6.3	6.9	
	④기타 계획	10만㎡	1.7	4.4	11.0	12.0	13	13	
	소 계		5.0	11.3	27.5	29.1	31.9	33.7	
5.성과품 작성	①보고서 작성 및 편집	10만㎡	0.3	0.5	1.2	1.8	2.0	2.2	주1 주2
	②관련도서 작성	10만㎡	0.2	0.3	0.6	1.4	1.5	1.9	
	소 계		0.5	0.8	1.8	3.2	3.5	4.1	
총 계			6.7	13.9	33.0	38.4	44.0	49.6	
6.기술협의	①공청회/주민설명회	1식	2.0	2.0	2.0	4.0	4.0	4.0	주3
	②주민간담회/시민계획단	1식	2.0	2.0	2.0	4.0	4.0	4.0	
	③위원회심의 지원	1식	2.0	2.0	2.0	4.0	4.0	4.0	
	④관계기관 협의	1식	2.0	2.0	2.0	4.0	4.0	4.0	
	소 계		8.0	8.0	8.0	16.0	16.0	16.0	

주 : ①경관시뮬레이션에 필요한 컴퓨터 그래픽 제작비용은 직접경비로 별도 계상한다.

②조감도, 투시도 제작비용은 직접경비로 별도 계상한다.

③기술협의는 2회 이내 기준이며, 횟수가 늘어날 경우 증가배수에 해당하는 작업품과 비용을 가산한다. (필요항목 선택적 적용)

2-5-2 개발사업경관계획 (사전경관계획 수립)

기술업무의 직능별 직접인력 소요작업량 (면적 30만㎡ 기준)

(단위 : 인·일/표준단위)

구 분	업무내용	표준단위	소요인력						비고
			기술사	특 급	고 급	중 급	초 급	보조원	
1.경관현황 분석	①현황조사	30만㎡	0.3	0.6	1.2	2.1	3.4	4.7	
	②관련법규 · 계획 검토	30만㎡	0.2	0.2	0.5	0.6	0.9	0.9	
	③현황종합분석	30만㎡	0.2	0.3	0.5	0.7	0.9	0.9	
	소 계		0.7	1.1	2.2	3.4	5.2	6.5	
2.기본방향 및 목표	①기본방향 및 목표	30만㎡	0.2	0.3	0.6	1.1	1.5	2.1	
	②전략수립	30만㎡	0.2	0.3	0.7	1.1	1.5	2.2	
	소 계		0.4	0.6	1.3	2.2	3.0	4.3	
3.경관구조 설정	①권역, 축, 거점의 설정	30만㎡	0.4	0.6	1.4	2.3	3.2	4.7	
	②블록(장소)별 세부구조 설정	30만㎡	0.5	0.7	1.4	2.4	3.3	4.8	
	소 계		0.9	1.3	2.8	4.7	6.5	9.5	
4.입체적 도시공간 구조 기본구상	①요소별 기본구상	30만㎡	1.2	2.6	6.4	6.6	7.3	7.9	
	②건축물경관계획	30만㎡	1.8	4.2	9.7	9.5	10.4	11.4	
	③가로경관계획	30만㎡	1.8	4.2	9.7	9.5	10.4	11.4	
	④공원·녹지경관계획	30만㎡	1.8	4.2	9.7	9.5	10.4	11.4	
	⑤색채 등 경관계획	30만㎡	2.0	4.2	11.8	14.6	16.1	17.6	
	소 계		8.6	19.4	47.3	49.7	54.6	59.7	
5.종합계획 및 통합지침 도작성	①종합계획 및 통합지침도 작성	30만㎡	0.3	0.4	0.9	1.8	2.0	2.1	
	소 계		0.3	0.4	0.9	1.8	2.0	2.1	
6.성과품 작성	①보고서 작성 및 편집	30만㎡	0.6	0.9	2.1	3.6	4.0	4.3	주1 주2
	소 계		0.6	0.9	2.1	3.6	4.0	4.3	
총 계			11.5	23.7	56.6	65.4	75.3	86.4	
7.기술협의	①공청회/주민설명회	1식	2.0	2.0	2.0	4.0	4.0	4.0	주3
	②주민간담회/시민계획단	1식	2.0	2.0	2.0	4.0	4.0	4.0	
	③위원회심의 지원	1식	2.0	2.0	2.0	4.0	4.0	4.0	
	④관계기관 협의	1식	2.0	2.0	2.0	4.0	4.0	4.0	
	소 계		8.0	8.0	8.0	16.0	16.0	16.0	

주 : ①경관시뮬레이션에 필요한 컴퓨터 그래픽 제작비용은 직접경비로 별도 계상한다.

②조감도, 투시도 제작비용은 직접경비로 별도 계상한다.

③기술협의는 2회 이내 기준이며, 횟수가 늘어날 경우 증가배수에 해당하는 작업품과 비용을 가산한다. (필요항목 선택적 적용)

2-5-3 경관상세계획

기술업무의 직능별 직접인력 소요작업량(면적 20만㎡ 기준)

(단위 : 인·일/표준단위)

구분	업무내용	표준 단위	소요인력						비고
			기술사	특 급	고 급	중 급	초 급	보조원	
1.경관현황조사·분석		20만㎡	0.8	1.3	2.5	4.0	6.0	7.5	
2.지구경관구상		20만㎡	1.0	1.5	3.3	5.5	7.5	11.0	
3.부문별 경관계획		20만㎡	10.0	22.5	55.0	57.8	63.6	69.9	
4.경관지침		20만㎡	0.5	0.8	1.5	2.5	3.5	5.0	
5.경관시뮬레이션구상		20만㎡	5.0	7.5	5.0	5.6	6.2	6.7	
6.성과품작성		20만㎡	1.0	1.5	3.5	6.3	6.9	7.6	주1 주2
총 계			18.3	35.1	70.8	81.7	93.7	107.7	
7.기술협의	①공청회/주민설명회	1식	2.0	2.0	2.0	4.0	4.0	4.0	주3
	②주민간담회/시민계획단	1식	2.0	2.0	2.0	4.0	4.0	4.0	
	③위원회심의 지원	1식	2.0	2.0	2.0	4.0	4.0	4.0	
	④관계기관 협의	1식	2.0	2.0	2.0	4.0	4.0	4.0	
	소 계		8.0	8.0	8.0	16.0	16.0	16.0	

주 : ①경관시뮬레이션에 필요한 컴퓨터 그래픽 제작비용은 직접경비로 별도 계상한다.

②조감도, 투시도 제작비용은 직접경비로 별도 계상한다.

③기술협의는 2회 이내 기준이며, 횟수가 늘어날 경우 증가배수에 해당하는 작업품과 비용을 가산한다. (필요항목 선택적 적용)

2-5-4 농·산·어촌경관계획

기술업무의 직능별 직접인력 소요작업량(면적 150만㎡ 기준)

(단위 : 인·일/표준단위)

구 분	업무내용	표준단위	소요인력						비고
			기술사	특 급	고 급	중 급	초 급	보조원	
1.경관현황 분석	①일반현황조사	150만㎡	0.5	1.0	1.0	1.5	2.0	3.0	
	②경관현황조사	150만㎡	3.0	8.0	10.5	15.5	18.5	18.5	
	③경관의식조사	150만㎡	1.5	2.0	4.0	4.0	6.0	6.5	
	④종합분석	150만㎡	0.5	1.5	1.5	3.0	3.0	4.5	
	소 계		5.5	12.5	17.0	24.0	29.5	32.5	
2.경관구상	①기본방향 및 미래상 설정	150만㎡	1.0	1.5	2.0	2.0	3.0	4.0	
	②경관구조 설정	150만㎡	1.0	2.0	3.0	2.0	3.5	4.0	
	소 계		2.0	3.5	5.0	4.0	6.5	8.0	
3.부문별 경관계획	①경관권역, 축, 거점계획	150만㎡	2.0	5.0	9.0	10.0	12.0	12.0	
	②요소별 계획	150만㎡	3.0	5.0	10.0	11.0	12.0	13.0	
	소 계		5.0	10.0	19.0	21.0	24.0	25.0	
4.실행계획	①실행계획	150만㎡	1.5	1.5	3.0	3.0	7.0	8.0	
	②경관시뮬레이션	150만㎡	0.5	1.0	1.5	2.5	2.0	2.5	
	소 계		2.0	2.5	4.5	5.5	9.0	10.5	
5.성과품 작성	①보고서 작성 및 편집	150만㎡	1.0	1.0	1.5	1.8	3.3	3.5	주1 주2
	②관련 도서 작성	150만㎡	0.5	0.5	1.5	1.7	3.2	3.5	
	소 계		1.5	1.5	3.0	3.5	6.5	7.0	
총 계			16.0	30.0	48.5	58.0	75.5	83.0	
6.기술협의	①공청회/주민설명회	1식	2.0	2.0	2.0	4.0	4.0	4.0	주3
	②주민간담회/시민계획단	1식	2.0	2.0	2.0	4.0	4.0	4.0	
	③위원회심의 지원	1식	2.0	2.0	2.0	4.0	4.0	4.0	
	④관계기관 협의	1식	2.0	2.0	2.0	4.0	4.0	4.0	
	소 계		8.0	8.0	8.0	16.0	16.0	16.0	

주 : ①경관시뮬레이션에 필요한 컴퓨터 그래픽 제작비용은 직접경비로 별도 계상한다.

②조감도, 투시도 제작비용은 직접경비로 별도 계상한다.

③기술협의는 2회 이내 기준이며, 횟수가 늘어날 경우 증가배수에 해당하는 작업품과 비용을 가산한다. (필요항목 선택적 적용)

2-5-5 경관기본설계

기술업무의 직능별 직접인력 소요작업량 (면적 1만㎡, 1㎞ 기준)

(단위 : 인·일/표준단위)

구 분	업무내용	표준단위	소요인력						비고
			기술사	특 급	고 급	중 급	초 급	보조원	
1.경관현황 분석	①일반현황조사	1만㎡외	0.1	0.2	0.4	0.5	0.8	1.2	
	②경관현황조사	1만㎡외	0.2	0.3	0.8	1.5	2.4	2.9	
	③국내외 사례검토	1만㎡외	0.2	0.3	0.6	0.8	1.2	1.6	
	④종합분석	1만㎡외	0.2	0.3	0.4	0.6	0.7	0.8	
	소 계		0.7	1.1	2.2	3.4	5.1	6.5	
2.경관구상	①기본방향 및 테마설정	1만㎡외	0.2	0.2	0.4	0.5	1.1	1.5	
	②공간구상	1만㎡외	0.2	0.4	1.0	2.0	2.2	3.2	
	③디자인구상	1만㎡외	0.2	0.4	1.0	1.1	2.2	3.2	
	④종합구상	1만㎡외	0.3	0.3	0.4	1.1	1.2	1.3	
	소 계		0.9	1.3	2.8	4.7	6.7	9.2	
3.실행계획	①디자인 대안 및 타당성 검토	1만㎡외	1.5	3.2	6.2	6.5	7.2	7.8	
	②항목별 디자인 제시	1만㎡외	3.0	6.4	12.4	13.1	14.5	15.9	
	③배치계획 및 세부계획	1만㎡외	3.0	6.4	12.4	13.1	14.5	15.9	
	④종합계획	1만㎡외	1.5	1.5	5.1	5.3	5.8	6.4	
	소 계		9.0	17.5	36.1	38.0	42.0	46.0	
4.경관기본 설계	①마스터플랜	1만㎡외	0.7	0.9	2.1	2.5	2.8	2.4	
	②기본설계도 작성	1만㎡외	1.1	2.3	4.5	4.6	5.2	5.6	
	③개략사업비 산출	1만㎡외	1.1	2.3	4.5	4.6	5.2	5.6	
	④기본 설계안 시뮬레이션	1만㎡외	1.0	2.2	4.4	4.6	5.2	5.6	
	소 계		3.9	7.7	15.5	16.3	18.4	19.2	
5.유지 및 관리방안 제시	①유지방안 및 유지관리 비용 산출	1만㎡외	1.0	1.1	1.5	1.9	2.2	2.6	
	②담당기관에서의 관리 범위 및 대상 등 규정	1만㎡외	1.0	1.1	1.5	1.9	2.2	2.6	
	소 계		2.0	2.2	3.0	3.8	4.4	5.2	
6.성과품 작성	①보고서 작성 및 편집	1만㎡외	0.6	1.0	2.3	4.1	4.5	4.9	주1 주2
	②관련 도서 작성	1만㎡외	0.2	0.4	0.7	1.4	1.5	1.6	
	소 계		0.8	1.4	3.0	5.5	6.0	6.5	
총 계			17.3	31.2	62.6	71.7	82.6	92.6	
7.기술협의	①공청회/주민설명회	1식	2.0	2.0	2.0	4.0	4.0	4.0	주3
	②주민간담회/시민계획단	1식	2.0	2.0	2.0	4.0	4.0	4.0	
	③위원회심의 지원	1식	2.0	2.0	2.0	4.0	4.0	4.0	
	④관계기관 협의	1식	2.0	2.0	2.0	4.0	4.0	4.0	
	소 계		8.0	8.0	8.0	16.0	16.0	16.0	

주 : ①경관시뮬레이션에 필요한 컴퓨터 그래픽 제작비용은 직접경비로 별도 계상한다.

②조감도, 투시도 제작비용은 직접경비로 별도 계상한다.

③기술협의는 2회 이내 기준이며, 횟수가 늘어날 경우 증가배수에 해당하는 작업품과 비용을 가산한다. (필요항목 선택적 적용)

2-6 주요업무내용

2-6-1 개발사업경관계획 (사전경관계획 비수립)

구 분	내 용
1.현황조사 및 분석	·경관자원 및 특성 ·관련 법규 및 계획 ·경관 종합분석
2.기본방향 및 목표	·기본방향 및 목표 설정 ·경관형성전략 수립
3.경관기본구상	·경관구조 설정 ·경관권역 기본구상 ·경관축 기본구상 ·경관거점 기본구상
4.경관부문별 계획	·건축물 경관계획 ·가로경관계획 ·공원 및 녹지 경관계획 ·그 밖의 계획

2-6-2 개발사업경관계획 (사전경관계획 수립)

구 분	내 용
1.경관현황분석	·현황조사 ·관련법규 · 계획 검토 ·현황종합분석
2.기본방향 및 목표	·기본방향 및 목표 ·전략수립
3.경관구조 설정	·권역, 축, 거점의 설정 ·블록(장소)별 세부구조 설정
4.입체적 도시공간구조 기본구상	·요소별 기본구상 ·건축물경관계획 ·가로경관계획 ·공원·녹지경관계획 ·색채 등 경관계획
5.종합계획 및 통합지침도 작성	·종합계획 및 통합지침도 작성

2-6-3 경관상세계획

구 분	내 용
1.경관현황조사·분석	·경관자원조사 ·관련 법규 및 유사사례 검토, 경관종합분석
2.지구경관구상	·기본방향 및 미래상 설정 ·경관형성전략 ·경관구조 설정
3.부문별 경관계획	·경관권역, 축, 거점계획 ·요소별 계획
4.경관지침	·장소별 지침, 요소별 지침
5.경관시뮬레이션구상	·경관시뮬레이션구상

2-6-4 농·산·어촌경관계획

구 분	내 용
1.경관현황분석	·일반현황조사 ·경관현황조사 ·경관의식조사, 종합분석
2.경관구상	·기본방향 및 미래상 설정 ·경관구조 설정
3.부문별 경관계획	·경관권역, 축, 거점계획 ·요소별 계획
4.실행계획	·실행계획 ·경관시뮬레이션

2-6-5 경관기본설계

구 분	내 용
1.경관현황분석	·일반현황조사 ·경관현황조사 ·국내·외 사례검토 ·종합분석
2.경관구상	·기본방향 및 테마설정 ·공간구상 ·디자인구상 ·종합구상
3.실행계획	·디자인 대안 및 타당성 검토 ·항목별 디자인 제시 ·배치계획 및 세부계획 ·종합계획
4.경관기본설계	·마스터플랜 ·기본설계도 작성 ·개략사업비 산출 ·기본 설계안 시뮬레이션
5.유지 및 관리방안 제시	·유지방안 및 유지관리 비용 산출 ·담당기관에서의 관리 범위 및 대상 등 규정

2-7 표준성과품

2-7-1 개발사업경관계획 (사전경관계획 비수립)

성과구분	표준성과도서			비 고
	구 분	규 격	제출부수	
보고서	·경관(부문)계획보고서	A4		발주자와 협의
	·경관심의도서	A4		경관심의 시

주 : ①제출부수 및 성과품 종류가 증가할 경우에는 증가배수에 해당하는 작업품과 비용을 가산한다.
②심의도서 및 기타 관련자료의 규격 및 제출부수는 발주자와의 협의에 의하여 비용을 산정한다.

2-7-2 개발사업경관계획 (사전경관계획 수립)

성과구분	표준성과도서			비 고
	구 분	규 격	제출부수	
보고서	·경관(부문)계획보고서	A4		발주자와 협의
	·경관심의도서	A4		경관심의 시
각종도면	·종합계획도	A4	1식	
	·경관통합지침도	A4	1식	
조감도	·조감도 또는 모형	A4	1식	

주 : ①제출부수 및 성과품 종류가 증가할 경우에는 증가배수에 해당하는 작업품과 비용을 가산한다.
②심의도서 및 기타 관련 자료의 규격 및 제출부수는 발주자와의 협의에 의하여 비용을 산정한다.
③도면의 축척은 발주자와의 협의를 통하여 계획의 내용을 표현하기에 적당한 축적 수준을 선택한다.

2-7-3 경관상세계획

성과구분	표준성과도서			비 고
	구 분	규 격	제출부수	
보고서	·경관(부문)계획보고서	A4		발주자와 협의
	·경관심의도서	A4		경관심의 시

주 : ①제출부수 및 성과품 종류가 증가할 경우에는 증가배수에 해당하는 작업품과 비용을 가산한다.
②심의도서 및 기타 관련 자료의 규격 및 제출부수는 발주자와의 협의에 의하여 비용을 산정한다.
③도면의 축척은 발주자와의 협의를 통하여 계획의 내용을 표현하기에 적당한 축적 수준을 선택한다.

2-7-4 농·산·어촌경관계획

성과구분	표준성과도서			비 고
	구 분	규 격	제출부수	
보고서	·경관계획보고서	A4		발주자와 협의
	·경관심의도서	A4		경관심의 시
조감도	·조감도 또는 투시도	A4	1식	

주 : ①제출부수 및 성과품 종류가 증가할 경우에는 증가배수에 해당하는 작업품과 비용을 가산한다.
②심의도서 및 기타 관련 자료의 규격 및 제출부수는 발주자와의 협의에 의하여 비용을 산정한다.
③도면의 축척은 발주자와의 협의를 통하여 계획의 내용을 표현하기에 적당한 축적 수준을 선택한다.

2-7-5 경관기본설계

성과구분	표준성과도서			비 고
	구 분	규 격	제출부수	
보고서	·경관계획보고서	A4		발주자와 협의
	·경관심의도서	A4		경관심의 시
각종도면	·종합계획도	A4	1식	
	·기본설계도	A4	1식	
조감도	·조감도 또는 투시도	A4	1식	

주 : ①제출부수 및 성과품 종류가 증가할 경우에는 증가배수에 해당하는 작업품과 비용을 가산한다.
②심의도서 및 기타 관련 자료의 규격 및 제출부수는 발주자와의 협의에 의하여 비용을 산정한다.
③도면의 축척은 발주자와의 협의를 통하여 계획의 내용을 표현하기에 적당한 축적 수준을 선택한다.

제3절 사회기반시설사업 등의 경관심의

3-1 정 의

○ 사회기반시설사업 경관심의 품셈기준은 「경관법」제26조에 따라 심의를 받도록 되어 있는 총사업비가 500억원 이상인 도로・철도시설・도시철도시설 사업, 총사업비가 300억원 이상인 하천시설 사업과 지방자치단체의 조례로 정하는 규모 이상의 사회기반시설 사업에 대한 경관심의 시 적용한다.

○ 건축물경관심의 품셈기준은 「경관법」제28조와 지방자치단체 조례에 따라 심의를 받도록 규정된 건축물에 대한 경관심의 시 적용한다.

사회기반시설사업 등의 경관심의의 체계

도로법, 철도건설법, 도시철도법, 하천법 등	사회기반시설사업	사회기반시설사업 경관심의
건축법 등	건축물	건축물 경관심의

3-2 자료제공의 전제

○ 당해 계획의 수립에 필요한 모든 관련 자료는 원칙적으로 발주자가 제공하는 것으로 하되, 발주자가 보유하지 않은 자료는 엔지니어링사업자가 수집한다.

○ 발주자가 제공하지 못하는 자료의 조사에는 그 규모·내용에 의거하여 별도의 엔지니어링사업대가를 산정하여 엔지니어링사업자가 수행하며, 당해 관련 자료의 보안이나 광범위한 자료가 요구될 경우는 조사·분석에 필요한 기간과 자료수집비용이 전제되어야 한다.

3-3 업무범위와 추진과정

3-3-1 업무범위

○ 사회기반시설사업경관심의, 건축물경관심의는 경관심의운영지침을 준용하여 작성한다.

3-3-2 추진과정

○ 관계법과 지침에 따라 절차를 이행하며 관계기관과의 협의, 전문가 자문, 심의 등에 소요되는 기간은 과업수행기간에서 제외하여 그 소요기간 만큼 과업수행기간을 연장하여야 한다.

3-4 품 산정의 원단위 산정과 기준

3-4-1 표준품 산정내역

○ 표준품 산정의 기준이 되는 비목은 제1장 총칙에서 제시한 비목을 중심으로 하였으며, 이는 경관계획수립에 필요한 사항만을 대상으로 한다.

○ 표준품 산정의 기본이 되는 직접인건비 품의 작업항목별 보할은 기존의 경험적 내용 및 항목별 업무의 난이도를 감안하여 설정토록 한다.

1. 사회기반시설사업 경관심의

종 별		내 용	단 위	비 고
직접비	직접인건비	1.경관현황분석 2.경관구상 3.부문별계획 4.경관시뮬레이션 구상 5.성과품 작성 6.기술협의	인·일 〃 〃 〃 〃 〃	
	직접경비	여비, 인쇄비, 조감도, 회의준비비, 현장 운영비 등	식	제1장 총칙참조
간접비	제경비	(직접인건비)×120%	〃	〃
	기술료	(직접인건비+제경비) ×30%	〃	〃

2. 건축물 경관심의

종 별		내 용	단 위	비 고
직접비	직접인건비	1.경관현황분석 2.경관구상 3.건축부문별계획 4.경관시뮬레이션 구상 5.성과품 작성 6.기술협의	인·일 〃 〃 〃 〃 〃	
	직접경비	여비, 인쇄비, 조감도, 회의준비비, 현장 운영비 등	식	제1장 총칙참조
간접비	제경비	(직접인건비)×120%	〃	〃
	기술료	(직접인건비+제경비) ×30%	〃	〃

3-4-2 산정기준

1. 계획·기준면적(거리)의 설정

○ 경관심의를 위한 기준면적(거리)은 대상지의 특성에 맞도록 설정하였으며, 관계법에 따른 기준 면적이나 관련 계획에서 사용하는 기준면적을 따른다.

1) 사회기반시설사업 경관심의

○ 선형적 특성이 강한 사업의 성격을 고려하여 기준거리 1km(기준면적 1만㎡), 최소거리 0.5km(최소면적 0.5만㎡)를 적용한다.

2) 건축물 경관심의

○ 연면적 1만㎡를 기준면적으로 하며, 연면적 0.5만㎡ 이하는 0.5만㎡를 적용한다.

2. 표준품의 산정방법

○ 표준품의 적용에 있어 기준면적(거리)와 기준면적(거리)의 차이에 따른 품 산정은 아래의 수정식에 따라 기준면적(거리)의 소요작업량을 수정하여 산정한다.

1) 사회기반시설사업 경관심의

○ 소요작업량 = 기준면적(거리) 소요작업량 × 면적(거리)보정계수(α) × 난이도보정계수(β)

2) 건축물 경관심의

○ 소요작업량 = 기준연면적 소요작업량 × 면적보정계수(α) × 난이도보정계수(β)

3. 계획안의 수정과 과업중지에 따른 품 산정방법

○ 계획안이 작성되고 자문이나 심의 등 기술협의과정을 거쳐 계획안이 확정된 후 발주자의 사정에 의하여 계획안이 일부변경 · 재작업이 수행되는 경우에는 그 변경·재작업의 정도에 따라 엔지니어링사업대가의 50~100% 이상 수준에서 비용을 추가 지급하여야 한다.

○ 과업수행 중 발주자의 사정에 따른 과업 중단으로 인해 정부 회계연도가 경과되어 현저한 비용의 차이가 발생하였을 경우에는 엔지니어링사업대가를 당해 신년도의 노임단가를 기준으로 재산정하여야 한다.

3-4-3 단위별 변화수정과 보정

1. 면적(거리)의 대소에 대한 작업량 보정계수 산정

○ 사업대상지의 면적이 기준 면적을 초과하거나 못 미치는 경우, 사업대상 건축물의 연면적이 기준 연면적을 초과하거나 못 미치는 경우, 직접인력 소요작업량의 산정을 위한 보정계수는 다음의 식에 의해 산정한다.

1) 사회기반시설사업 경관심의

$$\alpha_1 = (\frac{\text{계획면적(거리)}}{\text{기준면적(거리)}})^{0.6} = (\frac{A}{1})^{0.6}$$

α_1 = 보정계수,
A = 계획면적(만㎡), 계획거리(㎞)

계획단위별 보정계수

계획면적(만㎡) 계획거리(㎞)	보정계수 (α_1)	계획면적(만㎡) 계획거리(㎞)	보정계수 (α_1)
0.5	0.659	30	7.696
1	1.000	50	10.456
2	1.515	70	12.795
5	2.626	100	15.848
10	3.981	200	24.022

주 : 계획면적이 0.5만㎡ 미만인 경우에는 계획면적 0.5만㎡를 기준으로 하여 산정한다.
계획거리가 0.5㎞ 미만인 경우에는 계획거리 0.5㎞를 기준으로 하여 산정한다.

2) 건축물 경관심의

$$\alpha_2 = (\frac{\text{계획연면적}}{\text{기준연면적}})^{0.6} = (\frac{A}{1})^{0.6}$$

α_2 = 보정계수, A = 계획연면적(만㎡)

계획단위 면적별 보정계수

계획연면적(만㎡)	보정계수 (α_2)	계획연면적(만㎡)	보정계수 (α_2)
0.5	0.659	30	7.696
1	1.000	50	10.456
2	1.515	70	12.795
5	2.626	100	15.848
10	3.981	200	24.022

주 : 계획면적이 0.5만㎡ 미만인 경우에는 계획면적 0.5만㎡를 기준으로 하여 산정한다.

2. 사업성격에 따른 난이도 보정계수 산정

○ 사업의 특성에 따라 난이도 보정계수를 적용하여 산정한다.

1) 사회기반시설사업 경관심의

시설 특성에 따른 보정계수

구 분	시설특성 보정계수(β_1)
1. 일반형 : 고가구조물, 지하구조물, 터널, 교량 등의 입체구조물 불포함	1.00
2. 입체형 : 고가구조물, 지하구조물, 터널, 교량 등의 입체구조물 포함	1.75

2) 건축물 경관심의

용도특성에 따른 보정계수

구 분	용도특성 보정계수(β_2)
1. 단일용도형 : 상가를 제외한 단일용도 건축물	0.50
2. 복합용도형 : 상가 및 공동주택, 주상복합시설 등의 복합용도 건축물	1.00

3-5 표준단위 업무분류와 원단위

3-5-1 사회기반시설사업 경관심의

기술업무의 직능별 직접인력 소요작업량 (면적 1만㎡ 또는 거리 1㎞ 기준)

(단위 : 인·일/표준단위)

구 분	업무내용	표준 단위	소요인력						비고
			기술사	특 급	고 급	중 급	초 급	보조원	
1.경관현황 분석	①경관자원 및 경관특성	1만㎡외	0.1	0.2	0.5	0.7	1.0	1.3	
	②경관관련계획	1만㎡외	0.1	0.2	0.3	0.5	0.8	1.1	
	③종합분석	1만㎡외	0.1	0.1	0.2	0.4	0.6	0.6	
	소 계		0.3	0.5	1.0	1.6	2.4	3.0	
2.경관구상	①기본방향 및 테마 설정	1만㎡외	0.1	0.2	0.3	0.4	0.5	0.6	
	②공간 및 디자인 구상	1만㎡외	0.3	0.4	1.0	1.8	2.5	3.8	
	소 계		0.4	0.6	1.3	2.2	3.0	4.4	
3.부문별 계획	①구간별 경관설계	1만㎡외	2.4	5.4	13.2	14.4	15.6	15.6	
	②주요 시설(장소) 경관설계	1만㎡외	1.6	3.6	8.8	9.6	10.4	10.4	
	소 계		4.0	9.0	22.0	24.0	26.0	26.0	
4.경관시뮬레이션 구상	①조망점 선정	1만㎡외	0.3	0.4	0.3	0.4	0.4	0.3	
	②경관시뮬레이션	1만㎡외	1.7	2.6	1.7	2.2	2.2	1.7	
	소 계		2.0	3.0	2.0	2.6	2.6	2.0	
5.성과품 작성	①보고서 작성 및 편집	1만㎡외	0.3	0.4	1.1	1.9	1.9	1.9	주1 주2
	②관련 도서 작성	1만㎡외	0.1	0.2	0.3	0.5	1.1	1.1	
	소 계		0.4	0.6	1.4	2.4	3.0	3.0	
총 계			7.1	13.7	27.7	32.8	37.0	38.4	
6.기술협의	①관계기관협의	1식	2.0	2.0	2.0	4.0	4.0	4.0	주3
	②위원회심의	1식	2.0	2.0	2.0	4.0	4.0	4.0	
	소 계		4.0	4.0	4.0	8.0	8.0	8.0	

주 : ①경관시뮬레이션에 필요한 컴퓨터 그래픽 제작비용은 직접경비로 별도 계상한다.
②조감도, 투시도 제작비용은 직접경비로 별도 계상한다.
③기술협의는 2회 이내 기준이며, 횟수가 늘어날 경우 증가배수에 해당하는 작업품과 비용을 가산한다. (필요항목 선택적 적용)

3-5-2 건축물 경관심의

기술업무의 직능별 직접인력 소요작업량 (연면적 1만㎡ 기준)

(단위 : 인·일/표준단위)

구 분	업무내용	표준단위	소요인력						비고
			기술사	특 급	고 급	중 급	초 급	보조원	
1.경관현황분석	①경관자원 및 경관특성 ②경관관련계획 ③종합분석	1만㎡ 1만㎡ 1만㎡	0.1 0.1 0.1	0.2 0.1 0.1	0.3 0.3 0.3	0.8 0.4 0.8	0.8 0.4 0.8	1.0 1.0 1.0	
	소 계		0.3	0.4	0.9	2.0	2.0	3.0	
2.경관구상	①기본방향 및 테마 설정 ②경관구조 설정	1만㎡ 1만㎡	0.1 0.1	0.2 0.2	0.3 0.4	0.5 0.6	0.8 0.9	1.0 1.1	
	소 계		0.2	0.4	0.7	1.1	1.7	2.1	
3.건축부문별 계획	①배치·규모·형태계획 ②외부공간계획 ③옥외광고물 등 계획	1만㎡ 1만㎡ 1만㎡	1.1 1.2 0.5	2.5 2.6 1.2	5.1 5.0 2.5	6.1 5.1 2.8	6.0 6.1 2.9	6.1 6.0 2.9	
	소 계		2.8	6.3	12.6	14.0	15.0	15.0	
4.경관시뮬레이션 구상	①조망점 선정 ②경관시뮬레이션	1만㎡ 1만㎡	0.2 1.2	0.3 1.8	0.7 3.5	0.9 4.6	1.0 5.0	0.6 3.4	
	소 계		1.4	2.1	4.2	5.5	6.0	4.0	
5.성과품작성	① 보고서 작성 및 편집 ② 관련도서 작성	1만㎡ 1만㎡	0.2 0.1	0.2 0.2	0.5 0.5	0.9 0.8	1.1 1.0	1.1 1.0	주1 주2
	소 계		0.3	0.4	1.0	1.7	2.1	2.1	
총 계			5.0	9.6	19.4	24.3	26.8	26.2	
6.기술협의	①관계기관협의 ②위원회심의	1식 1식	2.0 2.0	2.0 2.0	2.0 2.0	4.0 4.0	4.0 4.0	4.0 4.0	주3
	소 계		4.0	4.0	4.0	8.0	8.0	8.0	

주 : ①경관시뮬레이션에 필요한 컴퓨터 그래픽 제작비용은 직접경비로 별도 계상한다.

②조감도, 투시도 제작비용은 직접경비로 별도 계상한다.

③기술협의는 2회 이내 기준이며, 횟수가 늘어날 경우 증가배수에 해당하는 작업품과 비용을 가산한다. (필요 항목 선택적 적용)

3-6 주요업무내용

3-6-1 사회기반시설사업 경관심의

구 분	내 용
1.경관현황분석	·경관자원 및 경관특성 ·경관관련계획 ·종합분석
2.경관구상	·기본방향 및 테마 설정 ·공간 및 디자인 구상
3.부문별계획	·구간별 경관설계 ·주요 시설(장소) 경관설계
4.경관시뮬레이션 구상	·조망점 선정 ·경관시뮬레이션

3-6-2 건축물 경관심의

구 분	내 용
1.경관현황분석	·경관자원 및 경관특성 ·경관관련계획 ·종합분석
2.경관구상	·기본방향 및 테마 설정 ·경관구조 설정
3.건축부문별계획	·배치·규모·형태계획 ·외부공간계획 ·옥외광고물 등 계획
4.경관시뮬레이션 구상	·조망점 선정 ·경관시뮬레이션

3-7 표준성과품

3-7-1 사회기반시설사업 경관심의

성과구분	표준성과도서			비 고
	구 분	규 격	제출부수	
보고서	·경관심의도서	A4		발주자와 협의

주 : ①심의도서 및 기타 관련자료의 규격 및 제출부수는 발주자와의 협의에 의하여 비용을 산정한다.
②제출부수에는 과업이 완료되기 이전 심의나 협의를 위하여 가제본된 보고서의 부수를 포함한다.

3-7-2 건축물 경관심의

성과구분	표준성과도서			비 고
	구 분	규 격	제출부수	
보고서	·경관심의도서	A4		발주자와 협의

주 : ①심의도서 및 기타 관련 자료의 규격 및 제출부수는 발주자와의 협의에 의하여 비용을 산정한다.
②제출부수에는 과업이 완료되기 이전 심의나 협의를 위하여 가제본된 보고서의 부수를 포함한다.

제8장 도시평가

제1절 국토계획평가
제2절 토지적성평가
제3절 재해취약성분석
제4절 환경성검토
제5절 교통성검토
제6절 경관성검토
제7절 사전재해영향성검토
제8절 교육환경평가
제9절 도시계획지속가능성평가
제10절 환경평가검증에 관한 업무

제1절 국토계획평가

1-1 정 의

○ 국토계획평가는 국토기본법 시행령 별표 중 1. 종합계획·지역계획을 대상으로 국토균형발전, 경쟁력 있는 국토여건의 조성 및 환경친화적인 국토관리 측면에서 국토의 지속가능한 발전에 기여하는지 여부와 국토관련 최상위계획인 국토종합계획과 부합하는지 여부를 평가하는 것이다.

1-2 자료제공의 전제

○ 국토계획평가에 필요한 모든 관련자료는 원칙적으로 발주자가 제공하는 것으로 하되, 발주자가 보유하지 않는 자료는 엔지니어링사업자가 수집한다.

○ 발주자가 제공하지 못하는 자료의 조사에 있어서는 그 규모·내용에 의거하여 별도의 엔지니어링사업대가를 산정하여 엔지니어링사업자가 수행하며, 관련자료의 기밀성과 광범위한 자료가 필요한 경우 조사·분석에 필요한 상당기간과 자료수집비용이 전제되어야 한다.

1-3 업무범위와 추진과정

1-3-1 업무범위

○ 국토계획평가업무의 범위는 국토계획평가를 위해서 갖추어야 할 제반도서 가운데 엔지니어링사업자의 기술적 능력이 요구되는 부분의 작성으로 하며, 국토계획평가센터와 관계기관 등 협의 및 심의를 포함한다.

1-3-2 추진과정

○ 타부처(관계기관)와 협의나 전문가 자문 등에 소요되는 기간은 과업수행기간에서 제외하여 그 소요기간만큼 과업수행기간을 연장하여야 한다.

국토계획평가 업무추진절차

국토계획평가 요청서 작성계획 수립	·검토위원회 등을 구성하여 세부 평가기준 및 평가방법 등 선정
국토계획평가 요청서 작성 및 제출	·검토위원회가 선정한 세부평가기준 및 방법에 따라 계획수립권자가 계획내용 분석 및 평가 후 국토교통부 제출
국토계획평가 및 심의	·평가요청서 검토 (국토계획평가센터 및 환경부) ·평가결과는 국토정책위원회 심의
평가결과 통보 및 반영	·평가결과를 계획수립권자에게 송부 ·계획수립권자는 조치결과를 참고하여 국토계획에 반영

1-4 품 산정의 원단위 산정과 기준

1-4-1 표준품 산정내역

○ 표준품 산정의 기준이 되는 비목은 제1장 총칙에서 제시한 비목을 중심으로 하였으며, 국토계획평가 업무에 필요한 사항만을 대상으로 한다.

○ 표준품 산정의 기본이 되는 직접인건비 품의 작업항목별 보할은 업무의 난이도를 감안하여 설정토록 한다.

종 별		내 용	세부항목	단위	비 고
직접비	직접인건비	1.기본구상	①세부평가기준 및 평가방법 수립	인·일	
		2.계획타당성 검토	①환경성 검토 ②계획타당성 검토	〃 〃	
		3.평가서 작성	①지역경쟁력 ②지역간 균형발전 ③국토 기간시설의 효율성 ④국토자원의 지속가능한 관리 ⑤저탄소 친환경적 국토이용 ⑥국토종합계획과의 정합성	〃 〃 〃 〃 〃 〃	
		4.성과품 작성	①자체평가표 작성 ②평가요청서 작성	〃	
		5.기술협의	①위원회심의 지원 ②관계기관 협의	〃 〃	
	직접경비	여비, 인쇄비, 조감도, 회의준비비, 현장운영비 등		식	제1장 총칙참조
간접비	제경비	(직접인건비) × 110%		〃	〃
	기술료	(직접인건비+제경비) × 30%		〃	〃

1-4-2 산정기준

1. 계획·기준면적 선정

○ 국토계획평가 업무에 있어서의 기준면적은 600㎢로 선정한다.

○ 계획면적은 과업면적을 원칙으로 한다.

2. 표준품의 산정방법

○ 표준품의 적용에 있어 기준면적과 계획면적의 차이에 따른 산정은 아래의 수정식에 따라 기준면적의 소요작업량을 수정하여 산정한다.

○ 소요작업량 = 기준면적 소요작업량 × 면적보정계수(α)

3. 평가서의 수정과 과업중지 등에 따른 산정방법

○ 평가서가 작성되고 주민의견, 의회보고 등 행정절차과정을 거쳐 계획안이 확정된 후 발주자의 사정에 의하여 평가서 내용이 일부변경·재작업이 수행되는 경우에는 그 변경·재작업의 정도에 따라 엔지니어링사업대가의 50～100% 수준에서 비용을 추가 지급하여야 한다.

○ 과업수행 중 발주자의 사정에 따른 과업 중단으로 인해 정부 회계연도가 경과되어 현저한 비용의 차이가 발생하였을 경우에는 엔지니어링사업대가를 당해 신년도의 노임단가를 기준으로 재산정하여야 한다.

1-4-3 단위별 변화수정과 보정

1. 면적의 대소에 대한 작업량 보정계수 산정

○ 국토계획평가에 관한 업무 계획면적이 기준면적을 초과하거나 이에 못 미치는 경우의 직접인력 소요작업량의 산정을 위한 각 작업내용별 면적보정계수(α)는 다음과 같이 산정한다.

$$\alpha = \left(\frac{\text{계획면적}}{\text{기준면적}}\right)^{0.2} = \left(\frac{A}{600}\right)^{0.2}$$

α = 보정계수
A = 계획면적(㎢)

계획면적(㎢)	보정계수(α)	계획면적(㎢)	보정계수(α)
100	0.699	1,000	1.108
300	0.871	2,000	1.272
500	0.964	3,000	1.380
600	1.000	4,000	1.461
800	1.059	5,000	1.528

주 : 계획면적이 100㎢미만인 경우에는 계획면적 100㎢를 기준으로 하여 산정한다.

2. 직접인건비 소요 작업량 산정

○ 계획면적의 대소에 따른 직접인력 소요작업량의 산정방법은 아래와 같이 기준면적의 직능별 직접인력 소요작업량에 계획단위 보정계수(α)를 곱하여 산출한다.

구 분	기준면적 (㎢)	총작업량(인·일)					
		기술사	특 급	고 급	중 급	초 급	보조원
국토계획평가	600	4.5α	11.0α	22.0α	17.0α	17.0α	8.0α

1-5 표준단위 업무분류와 원단위

기술업무의 직능별 직접인력에 의한 소요작업량 (면적 600㎢ 기준)

(단위 : 인·일/표준단위)

업무내용		표준단위	소요인력						비고
			기술사	특 급	고 급	중 급	초 급	보조원	
1.기본구상	①세부평가기준 및 평가방법수립	600㎢	1.0	2.0	2.0	2.0	2.0	0.0	
	소 계		1.0	2.0	2.0	2.0	2.0	0.0	
2.계획타당성 검토	①환경성 검토	600㎢	0.0	0.5	2.0	1.0	1.0	0.0	
	②계획타당성 검토	600㎢	0.0	0.5	2.0	1.0	1.0	0.0	
	소 계		0.0	1.0	4.0	2.0	2.0	0.0	
3.평가서 작성	①지역경쟁력	600㎢	0.5	1.0	2.0	2.0	2.0	0.0	
	②지역간 균형발전	600㎢	0.5	1.0	2.0	2.0	2.0	0.0	
	③국토 기간시설의 효율성	600㎢	0.5	1.0	2.0	2.0	2.0	0.0	
	④국토자원의 지속가능한 관리	600㎢	0.5	1.0	2.0	2.0	2.0	0.0	
	⑤저탄소 친환경적 국토이용	600㎢	0.5	1.0	2.0	2.0	2.0	0.0	
	⑥국토종합계획과의 정합성	600㎢	0.5	1.0	2.0	2.0	2.0	0.0	
	소 계		3.0	6.0	12.0	12.0	12.0	0.0	
4.성과품 작성	①자체평가표 작성	600㎢	0.5	1.0	2.0	1.0	1.0	4.0	
	②평가요청서 작성	600㎢	0.0	1.0	2.0	0.0	0.0	4.0	
	소 계		0.5	2.0	4.0	1.0	1.0	8.0	
총 계			4.5	11.0	22.0	17.0	17.0	8.0	
5.기술협의	①위원회심의 지원	1식	2.0	2.0	2.0	4.0	4.0	4.0	주1
	②관계기관 협의	1식	2.0	2.0	2.0	4.0	4.0	4.0	
	소 계		4.0	4.0	4.0	8.0	8.0	8.0	

주 : ①기술협의는 2회 이내 기준이며, 횟수가 늘어날 경우 증가배수에 해당하는 작업품과 비용을 가산한다. (필요항목 선택적 적용)

1-6 주요업무내용

구 분	업무내용	내 용
1.기본구상	①세부평가기준 및 평가방법 수립	·해당 국토계획의 특성과 내용에 적합한 세부평가기준과 평가방법을 수립
2.계획타당성검토	①환경성 검토	·환경친화적인 국토관리 측면에서 검토
	②계획타당성 검토	·국토종합계획과의 정합성과 국토계획의 타당성 검토
3.평가서작성	①지역경쟁력	·국토계획평가 세부평가기준에 의해 작성
	②지역간 균형발전	·국토계획평가 세부평가기준에 의해 작성
	③국토 기간시설의 효율성	·국토계획평가 세부평가기준에 의해 작성
	④국토자원의 지속가능한 관리	·국토계획평가 세부평가기준에 의해 작성
	⑤저탄소 친환경적 국토이용	·국토계획평가 세부평가기준에 의해 작성
	⑥국토종합계획과의 정합성	·국토계획평가 세부평가기준에 의해 작성

1-7 표준성과품

성과구분	표준성과도서			비 고
	구 분	규 격	제출부수	
관련도서	1.국토계획평가 요청서 2.국토계획평가서	1 식 1 식	50부 50부	

주 : 제출부수 및 성과품 종류가 증가할 경우에는 증가배수에 해당하는 작업품과 비용을 가산한다.

제2절 토지적성평가

2-1 정 의

○ 토지적성평가는 전 국토의 "환경친화적이고 지속가능한 개발"을 보장하고 개발과 보전이 조화되는 "선계획·후개발의 국토관리체계"를 구축하기 위하여 토지의 환경 생태적·물리적·공간적 특성을 종합적으로 고려하여 개별토지가 갖는 환경적·사회적 가치를 과학적으로 평가함으로써 도시·군기본계획을 수립하거나 도시·군관리계획을 입안하는 경우에 정량적·체계적인 판단 근거를 제공하기 위해 실시하는 기초조사이다.

2-2 자료제공의 전제

○ 토지적성평가는 각 지방자치단체별로 구축된 각종 공간정보, 전산자료 또는 개별공시지가조사를 위한 토지특성자료와 각 행정기관이 작성하여 제공하고 있는 공간정보 등을 활용하여 평가를 실시함으로 이에 대한 자료는 발주자가 제공하는 것으로 한다.

○ 발주자가 공간정보의 미구축으로 자료를 제공하지 못하는 경우, 혹은 대규모 필지의 포함 등으로 인하여 필지단위 분석이 아닌 일정 단위별로 토지적성평가의 실시가 필요한 경우, 이를 위한 공간정보(GIS DB)의 구축비용 등 추가적으로 발생되는 비용에 대하여는 발주자가 부담한다.

2-3 업무범위와 추진과정

2-3-1 업무범위

○ 토지적성평가는 기 구축된 지방자치단체의 각종 공간정보자료와 관련부처에서 생성되는 공간정보도면 등을 이용하여 평가방법 및 지표의 설정, 지표별 평가기준 설정 및 평가점수 산정, 특성별 적성값 산정, 종합적성값 산정, 표준화값 산정, 별도분류 등 일련의 과정을 업무범위로 한다.

○ 미 구축 공간정보의 추가구축은 관련품셈(건설공사표준품셈 21-24-6. 구조화편집)을 별도로 적용하여 계상한다.

2-3-2 추진과정

기본방향설정
GIS 기초자료 정비
선택지표의 검토
평가지표 / 기준의 설정
평가(프로그램운영)
feed back
특성별 적성값 산정
종합적성값 산정
표준화값 산정
별도분류
적성등급 적용기준 검토 지원

2-4 품 산정의 원단위 산정과 기준

2-4-1 표준품 산정내역

○ 표준품 산정의 기준이 되는 비목은 제1장 총칙에서 제시한 비목을 중심으로 하였으며, 이는 토지적성평가에 필요한 사항만을 대상으로 한다.

○ 표준품 산정의 기준이 되는 직접인건비 품의 작업항목별 보할은 업무의 난이도를 감안하여 설정토록 한다.

종 별		내 용	세부항목	단 위	비고
직접비	직접인건비	1.조사분석	①기초자료 정비	인·일	
		2.적성평가	①평가지표 선정 ②평가기준 설정 및 점수산정 ③적성값 산정 ④표준화값 산정 및 별도분류 ⑤적성등급 적용기준 검토지원	〃 〃 〃 〃 〃	
		3.성과품 작성	①평가보고서 작성	〃	
		4.기술협의	①위원회심의 및 자문 지원 ②관계기관 협의	〃	필요시
	직접경비	여비, 인쇄비, 회의준비비 등		식	제1장 총칙참조
간접비	제경비	(직접인건비)×110%		〃	〃
	기술료	(직접인건비+제경비) ×25%		〃	〃

주 : ① 공간정보의 미구축 지역에 대한 공간정보의 구축에 대해서는 관련품셈(건설공사표준품셈 21-24-6. 구조화편집)을 별도로 적용하도록 한다.

2-4-2 산정 기준

1. 계획·기준면적의 설정

○ 토지적성평가 과업면적은 비시가화지역을 체계적으로 관리·이용할 수 있도록 도시지역 중 주거지역, 상업지역, 공업지역과 「군사기지 및 군사시설 보호법」 제4조 및 제5조에 의해 지정된 민간인통제선 이북지역을 제외한 모든 지역으로 설정하며, 직능별 직접인력 소요원단위는 기 작성된 유사계획 등의 투입기술자 비율을 감안하여 설정한다.

2. 표준품의 산정방법

○ 표준품의 적용에 있어 면적에 따른 품 산정은 아래의 수정식에 따라 기준면적의 소요작업량을 수정하여 산정한다.

○ 소요작업량 = 기준면적 소요작업량 × 면적보정계수(α) × 밀도보정계수(β)

3. 평가서 내용의 수정과 과업중지에 따른 품 산정방법

○ 토지적성평가 결과 성과물이 작성되고, 관련계획이 행정절차과정을 거쳐는 과정에서 발주자의 사정에 의하여 성과물의 일부변경·재작업이 수행되는 경우 그 변경·재작업의 정도에 따라 엔지니어링기술자, 측량기술자, 소프트웨어기술자 노임단가의 50～100% 수준에서 비용을 추가 지급하여야 한다.

○ 과업수행 중 발주자의 사정에 따라 과업이 중단된 상태에서 정부 회계연도가 경과되어 현저한 비용의 차이가 발생하였을 경우에는 엔지니어링기술자, 측량기술자, 소프트웨어기술자 노임단가를 당해 신년도의 노임단가를 기준으로 재산정하여야 한다.

2-4-3 면적의 대소에 따른 작업량보정계수 산정

○ 토지적성평가의 과업면적이 기준면적을 초과하거나 못 미치는 경우의 직접인력 소요작업량의 산정을 위한 보정계수(α)는 다음의 식에 의해 산정한다.

$$\alpha = (\frac{\text{과업면적}}{\text{기준면적}})^{0.3} = (\frac{A}{50})^{0.3}$$

α = 면적보정계수
A = 과업면적(㎢)

토지적성평가 과업면적별 보정계수

과업면적(㎢)	보정계수(α)	과업면적(㎢)	보정계수(α)
50	1.000	500	1.995
100	1.231	800	2.297
200	1.516	1,100	2.528
300	1.712	1,400	2.717
400	1.866	1,700	2.880

주: 과업면적이 50㎢ 미만인 경우에는 과업면적 50㎢를 기준으로 하여 산정한다.

2-4-4 필지밀도의 과소에 따른 작업량보정계수 산정

○ 과업지역이 기준지역보다 필지밀도가 높은 경우의 직접인력 소요작업량의 산정을 위한 보정계수(β)는 다음의 식에 의해 산정한다.

토지적성평가 계획단위 밀도보정계수

구 분	밀도보정계수(β)
기성시가지지역(2,500필지/㎢이상)	2.50
시가지인접지역(1,000필지㎢이상 - 2,500필지/㎢미만)	1.75
농지지역(400필지/㎢이상 - 1,000필지/㎢미만)	1.37
산지지역 (400필지/㎢미만)	1.00

2-5 표준단위 업무분류와 원단위

기술업무의 직능별 직접인력 소요작업량 (50㎢ 기준)

(단위 : 인 · 일/표준단위)

업무내용		표준단위	소요인력						비고
			기술사	특급	고급	중급	초급	보조원	
1.조사분석	①기초자료 정비	50㎢	-	0.2	1.0	1.4	2.0	2.5	
	소계		-	0.2	1.0	1.4	2.0	2.5	
2.적성평가	①평가지표 선정	50㎢	1.0	2.0	6.0	10.0	14.0	18.0	
	②평가기준 설정 및 점수산정	50㎢	2.0	4.0	12.0	20.0	28.0	36.0	
	③적성값 산정	50㎢	2.0	6.0	16.0	20.0	40.0	52.0	
	④표준화값 산정 및 별도분류	50㎢	2.0	2.6	4.0	8.0	14.0	18.0	
	⑤적성등급 적용기준 검토 지원	50㎢	1.0	2.0	6.0	10.0	14.0	18.0	
	소계		8.0	16.6	44.0	68.0	110.0	142.0	
3.성과품작성	①평가보고서 작성	50㎢	1.0	2.6	5.2	8.0	17.0	18.0	
	소계		1.0	2.6	5.2	8.0	17.0	18.0	
계			9.0	19.4	50.2	77.4	129.0	162.5	
4.기술협의	① 위원회심의 및 자문 지원 ② 관계기관협의	1식 1식	2.0 2.0	2.0 2.0	2.0 2.0	4.0 4.0	4.0 4.0	4.0 4.0	
	소계		4.0	4.0	4.0	8.0	8.0	8.0	

주 : ①기술협의는 2회 이내 기준이며, 횟수가 늘어날 경우 증가배수에 해당하는 작업품과 비용을 가산한다. (필요항목 선택적 적용)
②공간정보의 미구축지역에 대한 소요작업량은 공간정보구축업무에 따른 별도 품셈(건설공사표준품셈)으로 산정하고 관련분야 대가기준인 측량 및 소프트웨어 기술자 노임단가를 적용하여 산정한다.
③ 토지적성평가결과의 도시·군관리계획에의 반영을 위한 작업품은 제3장 제3절 도시·군관리계획 품을 별도 적용한다.

2-6 주요업무내용

구분	업무내용
1. 기초자료확인정리	· 토지적성평가 프로그램 구동을 위한 공간정보(필지별 속성정보+도형정보)의 조사·정리 · 토지적성평가를 위한 기초자료 조사수집 및 입력 · 토지적성평가를 위한 기초자료 수정 및 구축
2. 평가지표 선정	· 지역특성에 맞는 개발적성 지표 및 보전적성 지표를 각각 2개씩 선정하는 과정 · 지역의 상황에 비추어 볼 때 지침에서 정한 선택지표를 사용하는 것이 적정·타당하지 아니한 경우에는 선택지표를 대체하여 사용할 다른 지표를 선정
3. 평가기준 설정 및 점수산정	· 평가기준 설정은 평가지표별로 지역상황에 따라 평가기준을 조정·확정하는 과정 · 평가지표별 평가점수 산정 절차는 필지별 특성값(격자단위로 실시하는 경우에는 격자별 특성값)을 평가기준에 따른 점수값으로 환산하는 과정
4. 적성값 산정	· 특성별 적성값 산정 절차는 토지의 종합적성에 영향을 미치는 개발 및 보전 특성별로 개발적성값과 보전적성값을 산출하는 과정 · 종합적성값 산정 절차는 개발적성값에서 보전적성값을 차감하여 필지별 종합적성값을 산출하는 과정
5. 표준화값 산정	· 필지별 종합적성값을 해당 시·군 전체의 평가대상토지의 적성값 평균과 표준편차를 이용하여 표준정규분포곡선상의 표준화값(Zi)으로 변환하는 과정
6. 별도 분류	· 평가대상토지의 객관적 상황에 비추어 보전적성의 판별이 명백한 경우 필지별 종합적성값에 관계없이 그 지역을 별도로 분류하는 과정
7. 적성등급 적용기준 검토 지원	· 지역의 공간구성에 관한 정책방향, 지역실정 등을 고려하여 용도지역별, 도시 · 군관리계획의 유형 등에 따라 적성등급 적용기준을 검토 지원
8. 평가보고서 작성	· 평가기준에 의한 적성평가결과를 설명하는 검토서 작성

2-7 표준성과품

성과구분	표준성과도서		비 고
	구 분	제출부수	
토지적성평가서	토지적성평가 지표 및 분석결과 (검토서)	1부	
CD	자료 CD	1식	CD

주: ①제출부수 및 성과품 종류가 증가할 경우에는 증가배수에 해당하는 작업품과 비용을 가산한다.
②계획보고서 및 기타 관련자료의 규격 및 제출부수는 발주자와의 협의에 의하여 비용을 산정한다.

제3절 재해취약성분석

3-1 정 의

○ 재해취약성 분석은 국토의 계획 및 이용에 관한 법률, 광역도시계획수립지침, 도시·군기본계획수립지침, 도시·군관리계획수립지침에 따라 광역도시계획, 도시·군기본계획, 도시·군관리계획 수립시 기후변화 재해 취약성을 사전에 분석하여 그 결과를 토지이용, 기반시설 등 부문별 계획에 반영하기 위하여 수행하는 업무를 말한다.

3-2 자료제공의 전제

○ 재해취약성 분석에 필요한 모든 관련자료는 원칙적으로 발주자가 제공하는 것으로 하되, 발주자가 보유하지 않는 자료는 엔지니어링사업자가 수집한다.

○ 발주자가 제공하지 못하는 자료의 조사에 있어서는 그 규모·내용에 의거하여 별도의 엔지니어링사업대가를 산정하여 엔지니어링사업자가 수행하며, 관련자료의 기밀성과 광범위한 자료가 필요한 경우 조사·분석에 필요한 상당기간과 자료수집비용이 전제되어야 한다.

3-3 업무범위와 추진과정

3-3-1 업무범위

○ 재해취약성 분석의 업무범위는 여러 도시와 개별도시의 자연재해와 풍수해 등 재해유형에 따른 재해취약성 분석을 위해서 갖추어야 할 제반도서 가운데 엔지니어링사업자의 기술적 능력이 요구되는 부분의 작성으로 하며, 관계기관 등 협의를 포함한다.

3-3-2 추진과정

○ 타부처(관계기관)와 협의나 전문가 자문 등에 소요되는 기간은 과업수행기간에서 제외하여 그 소요기간만큼 과업수행기간을 연장하여야 한다.

여러 도시 재해취약성 분석 업무추진절차

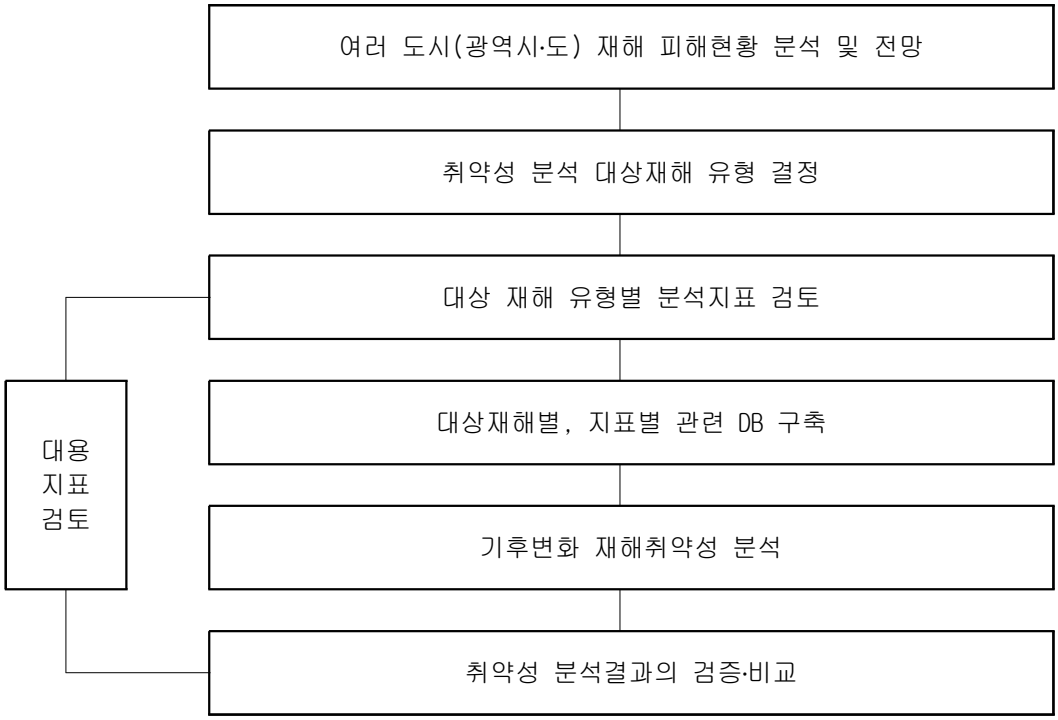

개별도시 재해취약성 분석 업무추진절차

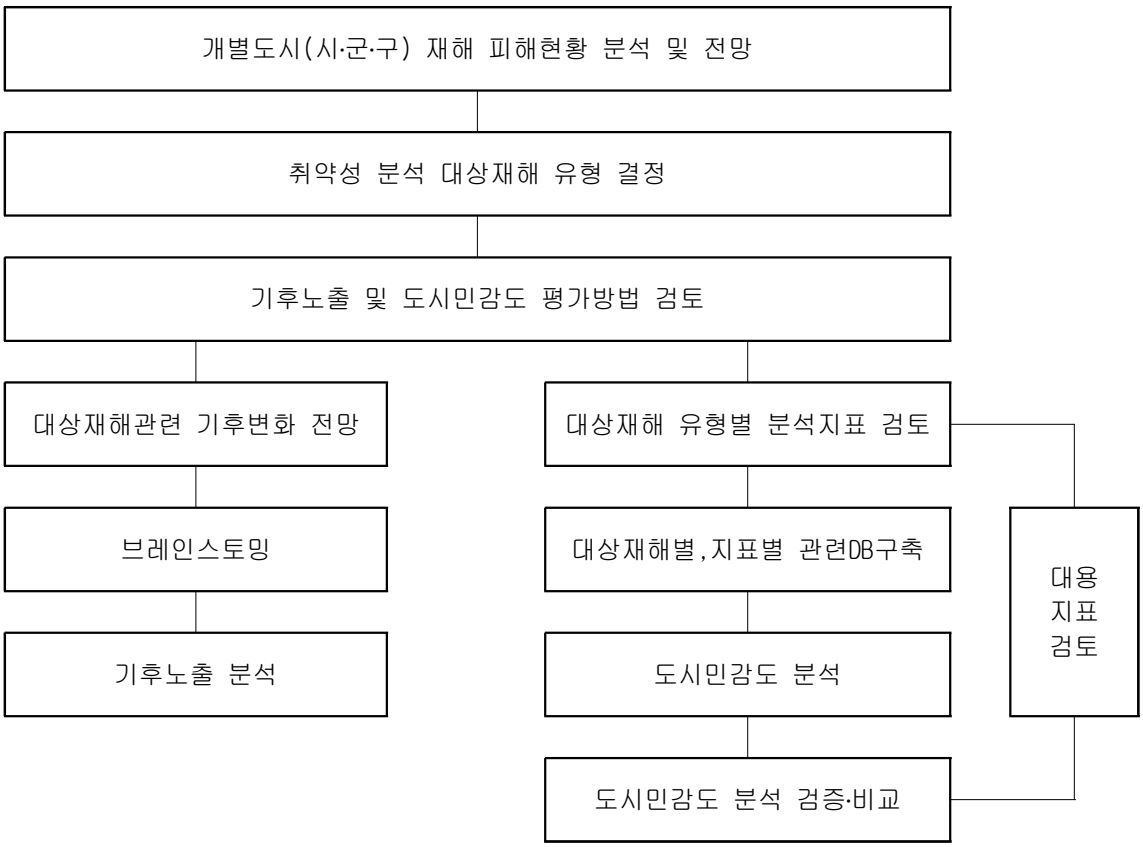

3-4 품 산정의 원단위 산정과 기준

3-4-1 표준품 산정내역

○ 표준품 산정의 기준이 되는 비목은 제1장 총칙에서 제시한 비목을 중심으로 하였으며, 재해취약성 분석 업무에 필요한 사항만을 대상으로 한다.

○ 표준품 산정의 기본이 되는 직접인건비 품의 작업항목별 보할은 업무의 난이도를 감안하여 설정토록 한다.

종 별		내 용	세부항목	단위	비 고
직접비	직접인건비	1.분석계획 수립	①분석유형설정 및 계획수립	인·일	
		2.기초현황조사	①일반현황조사 ②재해발생현황조사 ③관련계획 조사 ④조사자료 DB구축	〃 〃 〃 〃	
		3.도시기후변화 취약성분석	①재해취약성분석 구조 및 절차 수립 ②현재 기후노출 분석 ③도시민감도 분석 ④현재 취약성분석	〃 〃 〃 〃	
		4.공간분석 및 현장조사	①취약지역 공간분석 ②취약지 현장조사 ③현장조사 결과분석 ④현재취약지 평가 및 개선방향 수립 ⑤미래기후노출 분석 ⑥미래도시민감도 분석 ⑦미래취약성 분석 ⑧종합재해취약성 분석 ⑨전문가 의견 수렵	〃 〃 〃 〃 〃 〃 〃 〃 〃	
		5.정책제언	①요약 및 정책제언	〃	
		6.성과품 작성	①보고서 작성	〃	
		7.기술협의	①관계기관 협의	〃	
	직접경비	여비, 인쇄비, 조감도, 회의준비비, 현장운영비, 자료수집 등		식	제1장 총칙참조
간접비	제경비	(직접인건비) × 110%		식	〃
	기술료	(직접인건비+제경비) × 25%		식	〃

3-4-2 산정기준

1. 계획·기준면적 선정

○ 재해취약성 분석 업무에 있어서의 기준면적은 600㎢, 기준인구는 50만인으로 선정한다.

○ 계획면적은 과업면적, 계획인구는 목표인구를 원칙으로 한다.

2. 표준품의 산정방법

○ 표준품의 적용에 있어 기준면적과 계획면적의 차이, 기준인구와 계획인구의 차이, 재난유형에 따른 보정계수에 따른 품 산정은 아래의 수정식에 따라 기준면적 및 기준인구의 소요작업량을 수정하여 산정한다.

○ 소요작업량 = 기준면적(인구)소요작업량×면적보정계수(α)×인구보정계수(β)× 재난유형보정계수(γ)

3. 분석서의 수정과 과업중지에 따른 품 산정방법

○ 분석서가 작성되고 주민의견, 의회보고 등 행정절차과정을 거쳐 계획안이 확정된 후 발주자의 사정에 의하여 분석서 내용이 일부변경·재작업이 수행되는 경우에는 그 변경·재작업의 정도에 따라 엔지니어링사업대가의 50～100% 수준에서 비용을 추가 지급하여야 한다.

○ 과업수행 중 발주자의 사정에 따른 과업 중단으로 인해 정부 회계연도가 경과되어 현저한 비용의 차이가 발생하였을 경우에는 엔지니어링사업대가를 당해 신년도의 노임단가를 기준으로 재산정하여야 한다.

3-4-3 단위별 변화수정과 보정

1. 작업량 보정계수 산정

1) 면적의 대소에 대한 작업량 보정계수 산정

○ 계획면적이 기준면적을 초과하거나 못 미치는 경우의 직접인력 소요작업량의 산정을 위한 각 작업내용별 보정계수(α)는 다음과 같이 산정한다.

$$\alpha = \left(\frac{\text{계획면적}}{\text{기준면적}}\right)^{0.2} = \left(\frac{A}{600}\right)^{0.2}$$

α = 보정계수
A = 계획면적(㎢)

계획단위 면적별 보정계수

계획면적(㎢)	보정계수(α)	계획면적(㎢)	보정계수(α)
100	0.699	2,000	1.272
300	0.871	5,000	1.528
600	1.000	10,000	1.755
900	1.084	15,000	1.904
1,000	1.108	20,000	2.016

주 : 계획면적이 100㎢ 미만인 경우에는 계획면적 100㎢를 기준으로 하여 산정한다.

2) 인구의 대소에 대한 작업량 보정계수 산정

○ 계획인구가 기준인구를 초과하거나 못 미치는 경우의 직접인력 소요작업량의 산정을 위한 각 작업내용별 보정계수(β)는 다음과 같이 산정한다.

$$\beta = \left(\frac{\text{계획인구}}{\text{기준인구}}\right)^{0.25} = \left(\frac{A}{50}\right)^{0.25}$$

β = 보정계수
A = 계획인구(만인)

계획단위 인구별 보정계수

계획인구(만인)	보정계수(β)	계획인구(만인)	보정계수(β)
10	0.669	100	1.189
30	0.880	200	1.414
50	1.000	500	1.778
70	1.088	1000	2.115

주 : 계획인구가 10만인 미만인 경우에는 계획인구 10만인을 기준으로 하여 산정한다.

3) 재난유형에 따른 작업량 보정계수 산정

○ 재난 분석수와 풍수해비율을 감안한 재난유형 보정계수(γ)를 다음과 같이 산정한다.

계획단위 재난유형별 보정계수

구 분		재난분석개수					
		1개	2개	3개	4개	5개	6개
풍수해 비율	60% 이하	1.00	1.13	1.27	1.40	1.53	1.67
	61~65%	1.00	1.12	1.23	1.35	1.47	1.59
	66~70%	1.00	1.09	1.19	1.28	1.38	1.47
	71~75%	1.00	1.07	1.15	1.22	1.30	1.37
	76~80%	1.00	1.06	1.11	1.17	1.23	1.28
	81~85%	1.00	1.04	1.08	1.12	1.16	1.20
	86~90%	1.00	1.03	1.05	1.08	1.11	1.14
	91~95%	1.00	1.02	1.03	1.05	1.06	1.08
	96% 이상	1.00	1.01	1.02	1.03	1.03	1.04

2. 직접인건비 소요 작업량 산정

○ 계획면적와 계획인구 대소에 따른 직접인력 소요작업량은 아래와 같이 기준면적과 기준인구의 직능별 직접인력 소요작업량에 계획단위 보정계수(α, β)와 재난유형 보정계수(γ)를 곱하여 산출한다.

구 분	기준면적 기준인구	총작업량(인·일)					
		기술사	특 급	고 급	중 급	초 급	보조원
재해취약성 분석	600㎢, 50만인	7.1αβγ	11.4αβγ	21.4αβγ	34.3αβγ	31.2αβγ	29.8αβγ

3-5 표준단위 업무분류와 원단위

기술업무의 직능별 직접인력에 의한 소요작업량 (600㎢ 기준, 50만인 기준, 풍수해비율80% 기준)

(단위 : 인·일/표준단위)

업무내용		표준단위	소요인력						비고
			기술사	특 급	고 급	중 급	초 급	보조원	
1.분석계획수립	①분석유형설정 및 계획수립	600㎢외	0.4	0.4	0.9	0.7	0.4	0.4	
	소 계		0.4	0.4	0.9	0.7	0.4	0.4	
2.기초현황조사	①일반현황조사	600㎢외	-	0.1	0.2	0.7	1.1	1.1	
	②재해발생현황조사	600㎢외	0.1	0.1	0.3	0.8	1.3	1.5	
	③관련계획 조사	600㎢외	0.1	0.1	0.2	0.7	0.8	0.9	
	④조사자료 DB구축	600㎢외	0.1	0.4	0.9	1.5	2.0	2.5	
	소 계		0.3	0.7	1.6	3.7	5.2	6.0	
3.도시기후변화취약성분석	①재해취약성분석 구조 및 절차 수립	600㎢외	0.3	0.4	1.0	1.5	1.1	0.6	
	②현재 기후노출 분석	600㎢외	0.3	0.5	1.3	2.2	1.7	2.2	
	③도시민감도 분석	600㎢외	0.3	0.6	1.1	2.5	1.9	1.5	
	④현재 취약성분석	600㎢외	0.3	0.4	0.9	1.6	0.8	0.7	
	소 계		1.2	1.9	4.3	7.8	5.5	5.0	
4.공간분석 및 현장조사	①취약지역 공간분석	600㎢외	0.2	1.0	1.5	2.7	3.3	3.8	
	②취약지 현장조사	600㎢외	0.6	1.0	1.8	2.5	3.0	3.0	
	③현장조사 결과 분석	600㎢외	0.5	0.6	1.2	1.8	1.0	0.9	
	④현재취약지 평가 및 개선방향 수립	600㎢외	0.6	0.8	0.7	1.5	0.8	0.4	
	⑤미래기후노출 분석	600㎢외	0.5	0.8	1.5	2.0	1.5	0.9	
	⑥미래도시민감도 분석	600㎢외	0.5	0.8	1.5	2.0	1.5	0.9	
	⑦미래취약성 분석	600㎢외	0.5	0.8	1.5	2.0	1.5	0.9	
	⑧종합재해취약성 분석	600㎢외	0.2	0.4	1.5	2.7	3.3	3.8	
	⑨전문가 의견수렴	600㎢외	0.6	1.0	1.5	1.8	2.2	2.0	
	소 계		4.2	7.2	12.7	19.0	18.1	16.6	
5.정책제언	①요약 및 정책제언	600㎢외	0.6	0.8	0.7	1.1	0.6	0.4	
	소 계		0.6	0.8	0.7	1.1	0.6	0.4	
6.성과품작성	①보고서 작성	600㎢외	0.4	0.4	1.2	2.0	1.4	1.4	
	소 계		0.4	0.4	1.2	2.0	1.4	1.4	
계			7.1	11.4	21.4	34.3	31.2	29.8	

3-6 주요업무내용

구 분	업무내용	내 용
1.분석계획수립	①분석유형설정 및 계획수립	·재난 유형설정 및 분석계획 수립
2.기초현황조사	①일반현황조사	·조사대상지역의 일반현황 조사
	②재해발생현황조사	·유형별 재해발생 현황조사
	③관련계획 조사	·재해취약성 분석과 관련된 계획 조사
	④조사자료 DB구축	·기초현황조사 DB구축
3.도시기후변화 취약성분석	①재해취약성분석 구조 및 절차 수립	·재해취약성 분석 매뉴얼에 의한 분석구조 및 절차 수립
	②현재 기후노출 분석	·재해취약성 분석 매뉴얼에 의한 현재 기후노출 분석
	③도시민감도 분석	·재해취약성 분석 매뉴얼에 의한 도시민감도 분석
	④현재 취약성분석	·재해취약성 분석 매뉴얼에 의한 현재 취약성 분석
4. 공간분석 및 현장조사	①취약지역 공간분석	·취약지역 공간분석
	②취약지 현장조사	·현장조사를 통한 검증(민감 취약지)
	③현장조사 결과분석	·현장조사 결과를 통한 취약성분석 보완
	④현재취약지 평가 및 개선 방향 수립	·취약지 평가 및 개선방향 수립
	⑤미래기후노출 분석	·재해취약성 분석 매뉴얼에 의한 미래 기후노출 분석
	⑥미래도시민감도 분석	·재해취약성 분석 매뉴얼에 의한 미래 도시민감도 분석
	⑦미래취약성 분석	·재해취약성 분석 매뉴얼에 의한 미래 취약성 분석
	⑧종합재해취약성 분석	·재해취약성 분석 매뉴얼에 의한 종합 취약성 분석
	⑨전문가 의견수렴	·공간분석에 따른 전문가 의견수렴
5.정책제언	①요약 및 정책제언	·재해취약성 분석 매뉴얼에 의한 요약 및 정책 제언

3-7 표준성과품

성과구분	표준성과도서			비 고
	구 분	규 격	제출부수	
관련도서	1. 재해취약성 분석 기초자료집 2. 재해취약성 분석 보고서	1 식 1 식	3부 50부	

주 : 제출부수 및 성과품 종류가 증가할 경우에는 증가배수에 해당하는 작업품과 비용을 가산한다.

제4절 환경성검토

4-1 정 의

○ 환경성검토는 국토의 계획 및 이용에 관한 법률, 도시·군관리계획수립지침에 따라 도시·군관리계획의 입안과정에서 도시·군관리계획이 환경에 미치는 영향을 검토하여 환경부하 요인을 사전에 해소하거나 최소화함으로써 개발과 환경을 조화시키기 위하여 실시하는 검토를 말한다.

4-2 자료제공의 전제

○ 환경성검토에 필요한 모든 관련자료는 원칙적으로 발주자가 제공하는 것으로 하되, 발주자가 보유하지 않는 자료는 엔지니어링사업자가 수집한다.

○ 발주자가 제공하지 못하는 자료의 조사에 있어서는 그 규모·내용에 의거하여 별도의 엔지니어링사업대가를 산정하여 엔지니어링사업자가 수행하며, 관련자료의 기밀성과 광범위한 자료가 필요한 경우 조사·분석에 필요한 상당기간과 자료수집비용이 전제되어야 한다.

4-3 업무범위와 추진과정

4-3-1 업무범위

○ 환경성검토의 업무범위는 현황조사, 대안설정, 환경영향 및 저감방안 수립, 종합평가 등 환경성검토를 위해서 갖추어야 할 제반도서 가운데 엔지니어링사업자의 기술적 능력이 요구되는 부분의 작성으로 하며, 관계기관 등 협의를 포함한다.

4-3-2 추진과정

○ 타부처(관계기관)와 협의나 전문가 자문 등에 소요되는 기간은 과업수행기간에서 제외하여 그 소요기간만큼 과업수행기간을 연장하여야 한다.

환경성검토 업무추진절차

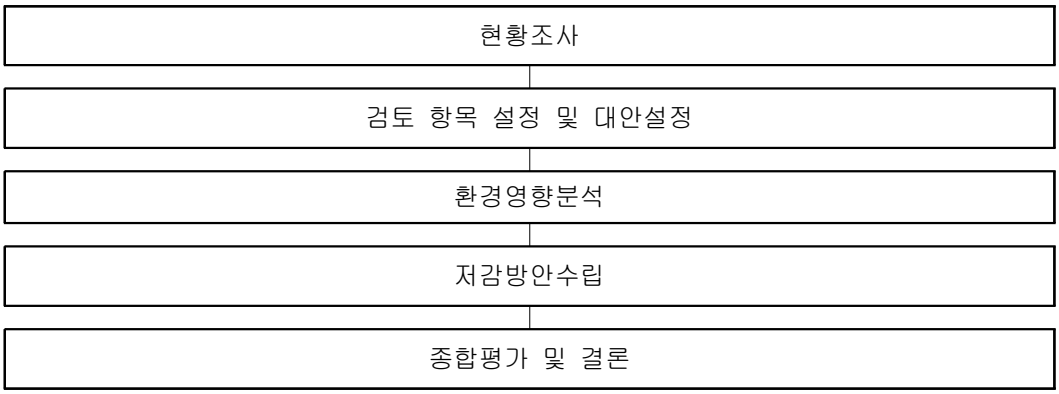

4-4 품 산정의 원단위 산정과 기준

4-4-1 표준품 산정내역

○ 표준품 산정의 기준이 되는 비목은 제1장 총칙에서 제시한 비목을 중심으로 하였으며, 환경성검토 업무에 필요한 사항만을 대상으로 한다.

○ 표준품 산정의 기본이 되는 직접인건비 품의 작업항목별 보할은 업무의 난이도를 감안하여 설정토록 한다.

종 별		내 용	세부항목	단위	비 고
직접비	직접인건비	1.현황조사	①행정계획의 개요 ②대상지역의 현황	인·일 〃	
		2.대안설정	①검토항목 설정 ②대안의 설정	〃 〃	
		3.환경영향	①계획의 적정성 및 입지의 타당성 ②환경영향분석	〃 〃	
		4.저감방안수립	①저감방안수립	〃	
		5.종합평가	①협의회 의견수렴 결과 ②주민 의견수렴 결과 ③종합평가 및 결론	〃 〃 〃	
		6.기술협의	①공청회 / 주민설명회 ②주민간담회 / 시민계획단 ③위원회심의 지원 ④관계기관 협의	〃 〃 〃 〃	
	직접경비	여비, 인쇄비, 조감도, 회의준비비, 현장운영비 등		식	제1장 총칙참조
간접비	제경비	(직접인건비) × 110%		〃	〃
	기술료	(직접인건비+제경비) × 30%		〃	〃

4-4-2 산정기준

1. 계획·기준면적 선정

○ 환경성검토 업무에 있어서의 기준면적은 10만㎡로 선정한다.

○ 계획면적은 과업면적을 원칙으로 한다.

2. 표준품의 산정방법

○ 표준품의 적용에 있어 기준면적과 계획면적의 차이는 아래의 수정식에 따라 기준면적의 소요작업량을 수정하여 산정한다.

○ 소요작업량 = 기준면적 소요작업량 × 면적보정계수(α)

3. 검토서의 수정과 과업중지 등에 따른 산정방법

○ 환경성검토서가 작성되어 확정된 후 발주자의 사정에 의하여 환경성검토서가 변경·재작업이 수행되는 경우에는 그 일부변경·재작업의 정도에 따라 엔지니어링사업대가의 50～100% 수준에서 비용을 추가 지급하여야 한다.

○ 과업수행 중 발주자의 사정에 따른 과업 중단으로 인해 정부 회계연도가 경과되어 현저한 비용의 차이가 발생하였을 경우에는 엔지니어링사업대가를 당해 신년도의 노임단가를 기준으로 재산정하여야 한다.

4-4-3 단위별 변화수정과 보정

1. 면적의 대소에 대한 작업량 보정계수 산정

○ 도시·군관리계획 계획면적이 기준면적을 초과하거나 못 미치는 경우의 직접인력 소요작업량의 산정을 위한 각 작업내용별 보정계수(α)는 다음과 같이 산정한다.

$$\alpha = (\frac{\text{계획면적}}{\text{기준면적}})^{0.2} = (\frac{A}{10})^{0.2}$$

α = 보정계수
A = 계획면적(만㎡)

계획단위 면적별 보정계수

계획면적(만㎡)	보정계수(α)	계획면적(만㎡)	보정계수(α)
3	0.786	100	1.585
5	0.871	150	1.719
10	1.000	200	1.821
20	1.149	250	1.904
50	1.380	300	1.974

주 : 계획면적이 3만㎡ 미만인 경우에는 계획면적 3만㎡를 기준으로 하여 산정한다.

2. 직접인건비 소요 작업량 산정

○ 계획면적 대소에 따른 직접인력 소요작업량은 아래와 같이 기준면적의 직능별 직접인력 소요작업량에 계획단위 보정계수(α)를 곱하여 산출한다.

구 분	기준면적	총작업량 (인·일)					
		기술사	특 급	고 급	중 급	초 급	보조원
환경성검토	10만㎡	7.9α	16.0α	27.2α	46.5α	38.6α	19.1α

4-5 표준단위 업무분류와 원단위

기술업무의 직능별 직접인력 소요작업량 (면적10만㎡ 기준)

(단위 : 인·일/표준단위)

업무내용		표준단위	소요인력						비 고
			기술사	특 급	고 급	중 급	초 급	보조원	
1.현황조사	①행정계획의 개요	10만㎡	0.3	0.6	1.0	1.0	0.8	0.4	
	②대상지역의 현황	10만㎡	0.2	0.4	0.4	0.8	0.8	0.4	
	소 계		0.5	1.0	1.4	1.8	1.6	0.8	
2.대안설정	①검토항목 설정	10만㎡	0.1	0.2	0.2	0.3	0.4	0.2	
	②대안의 설정	10만㎡	3.7	7.4	12.8	22.2	18.3	9.1	
	소 계		3.8	7.6	13	22.5	18.7	9.3	
3.환경영향	①계획의 적정성 및 입지의 타당성	10만㎡	0.2	0.4	0.7	1.5	1.8	0.9	
	②환경영향분석	10만㎡	0.4	0.8	2.0	3.0	2.0	1.0	
	소 계		0.6	1.2	2.7	4.5	3.8	1.9	
4.저감방안 수립	①저감방안수립	10만㎡	1.7	3.3	4.9	5.7	2.1	1.0	
	소 계		1.7	3.3	4.9	5.7	2.1	1.0	
5.종합평가	①협의회 의견수렴결과	10만㎡	0.4	0.9	0.8	1.4	1.9	0.9	
	②주민 의견수렴 결과	10만㎡	0.3	0.7	2.0	6.1	6.7	3.3	
	③종합평가 및 결론	10만㎡	0.6	1.3	2.4	4.5	3.8	1.9	
	소 계		1.3	2.9	5.2	12	12.4	6.1	
총 계			7.9	16.0	27.2	46.5	38.6	19.1	
6.기술협의	①공청회/주민설명회	1식	2.0	2.0	2.0	4.0	4.0	4.0	주1
	②주민간담회/시민계획단	1식	2.0	2.0	2.0	4.0	4.0	4.0	
	③위원회심의 지원	1식	2.0	2.0	2.0	4.0	4.0	4.0	
	④관계기관 협의	1식	2.0	2.0	2.0	4.0	4.0	4.0	
	소 계		8.0	8.0	8.0	16.0	16.0	16.0	

주 : ①기술협의는 2회 이내 기준이며, 횟수가 늘어날 경우 증가배수에 해당하는 작업품과 비용을 가산한다. (필요항목 선택적 적용)

4-6 주요업무내용

구 분	업무내용	내 용
1.현황조사	①행정계획의 개요	·환경성검토 대상인 행정계획의 개요 작성
	②대상지역의 현황	·대상지역의 자연환경, 인문환경 등 현황을 조사·분석
2.대안설정	①검토항목 설정	·환경성검토의 항목을 설정
	②대안의 설정	·환경성검토의 대안을 설정
3.환경영향	①계획의 적정성 및 입지의 타당성	·행정계획의 적정성과 법적 입지의 타당성검토
	②환경영향분석	·환경적인 위해요인 등 환경영향을 분석
4.저감방안 수립	①저감방안수립	·환경영향을 최소화할 수 있는 저감방안 수립
5.종합평가	①협의회 의견수렴결과	·환경성검토협의회에서 제시의견 검토
	②주민 의견수렴 결과	·주민 의견 청취시 제시의견 검토
	③종합평가 및 결론	·환경성검토의 종합평가 및 결론 제시

4-7 표준성과품

성과구분	표준성과도서			비 고
	구 분	규 격	제출부수	
관련도서	1. 환경성검토 기초자료집 2. 환경성검토 보고서	1 식 1 식	3부 50부	

주 : 제출부수 및 성과품 종류가 증가할 경우에는 증가배수에 해당하는 작업품과 비용을 가산한다.

제5절 교통성검토

5-1 정 의

○ 교통성검토는 국토의 계획 및 이용에 관한 법률, 도시·군관리계획수립지침에 따라 도시·군관리계획의 입안과정에서 도시·군관리계획이 교통에 미치는 문제점과 영향을 분석하여 개선방안을 제시하는 업무를 말한다.

5-2 자료제공의 전제

○ 교통성검토에 필요한 모든 관련자료는 원칙적으로 발주자가 제공하는 것으로 하되, 발주자가 보유하지 않는 자료는 엔지니어링사업자가 수집한다.

○ 발주자가 제공하지 못하는 자료의 조사에 있어서는 그 규모·내용에 의거하여 별도의 엔지니어링사업대가를 산정하여 엔지니어링사업자가 수행하며, 관련자료의 기밀성과 광범위한 자료가 필요한 경우 조사·분석에 필요한 상당기간과 자료수집비용이 전제되어야 한다.

5-3 업무범위와 추진과정

5-3-1 업무범위

○ 교통성검토의 업무범위는 현황분석, 교통시설계획, 교통시설운영계획 등을 수립하기 위해서 갖추어야 할 제반도서 가운데 엔지니어링사업자의 기술적 능력이 요구되는 부분의 작성으로 하며, 관계기관 등 협의를 포함한다.

5-3-2 추진과정

○ 타부처(관계기관)와 협의나 전문가 자문 등에 소요되는 기간은 과업수행기간에서 제외하여 그 소요기간만큼 과업수행기간을 연장하여야 한다.

교통성검토 업무추진절차

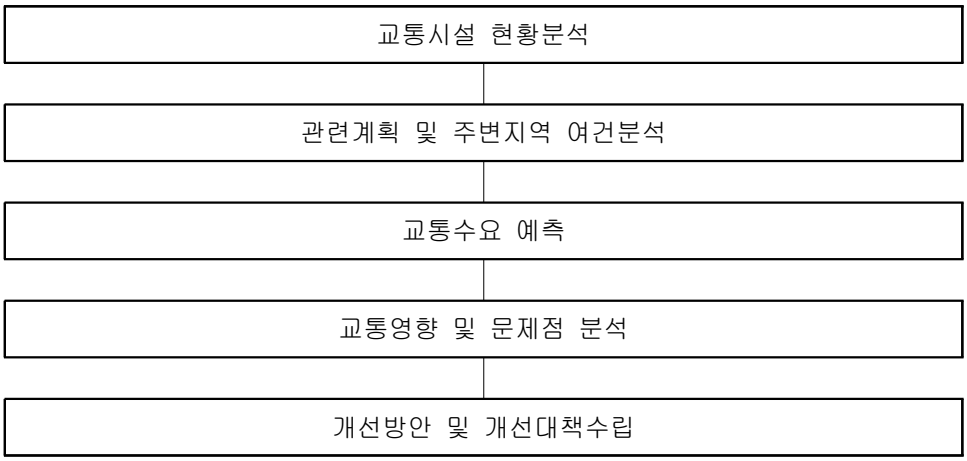

5-4 품 산정의 원단위 산정과 기준

5-4-1 표준품 산정내역

○ 표준품 산정의 기준이 되는 비목은 제1장 총칙에서 제시한 비목을 중심으로 하였으며, 교통성검토 업무에 필요한 사항만을 대상으로 한다.

○ 표준품 산정의 기본이 되는 직접인건비 품의 작업항목별 보할은 업무의 난이도를 감안하여 설정토록 한다.

종 별		내 용		단위	비 고
직접비	직접인건비	1.개요	①서론 ②도시·군관리계획 개요	인·일 〃	
		2.현황분석	①교통시설 현황분석	〃	
		3.교통계획	①교통시설계획 ②교통시설운영계획	〃 〃	
		4.성과품작성	①성과품작성	〃	
		5.기술협의	①공청회 / 주민설명회 ②주민간담회 / 시민계획단 ③위원회 심의 지원 ④관계기관 협의	〃 〃 〃 〃	
	직접경비	여비, 인쇄비, 조감도, 회의준비비, 현장운영비 등		식	제1장 총칙참조
간접비	제경비	(직접인건비) × 110%		식	〃
	기술료	(직접인건비+제경비) × 30%		식	〃

5-4-2 산정기준

1. 계획·기준면적 선정

○ 교통성검토 업무에 있어서의 기준면적은 10만㎡로 선정한다.

○ 계획면적은 과업면적을 원칙으로 한다.

2. 표준품의 산정방법

○ 표준품의 적용에 있어 기준면적과 계획면적의 차이는 아래의 수정식에 따라 기준면적의 소요작업량을 수정하여 산정한다.

○ 소요작업량 = 기준면적 소요작업량 × 면적보정계수(α)

3. 검토서의 수정과 과업중지 등에 따른 산정방법

○ 교통성검토서가 작성되어 확정된 후 발주자의 사정에 의하여 교통성검토서가 변경·재작업이 수행되는 경우에는 그 일부변경·재작업의 정도에 따라 엔지니어링사업대가의 50～100% 수준에서 비용을 추가 지급하여야 한다.

○ 과업수행 중 발주자의 사정에 따른 과업 중단으로 인해 정부 회계년도가 경과되어 현저한 비용의 차이가 발생하였을 경우에는 엔지니어링사업대가를 당해 신년도의 노임단가를 기준으로 재산정하여야 한다.

5-4-3 단위별 변화수정과 보정

1. 면적의 대소에 대한 작업량 보정계수 산정

○ 도시·군관리계획 계획면적이 기준면적을 초과하거나 못 미치는 경우의 직접인력 소요작업량의 산정을 위한 각 작업내용별 보정계수(α)는 다음과 같이 산정한다.

$$\alpha = (\frac{\text{계획면적}}{\text{기준면적}})^{0.6} = (\frac{A}{10})^{0.6}$$

α = 보정계수
A = 계획면적(만㎡)

계획단위 면적별 보정계수

계획면적(만㎡)	보정계수(α)	계획면적(만㎡)	보정계수(α)
3	0.486	100	3.981
5	0.660	150	5.078
10	1.000	200	6.034
20	1.516	250	6.899
50	2.627	300	7.696

주 : 계획면적이 3만㎡ 미만인 경우에는 계획면적 3만㎡를 기준으로 하여 산정한다.

2. 직접인건비 소요 작업량 산정

○ 계획면적 대소에 따른 직접인력 소요작업량은 아래와 같이 기준면적의 직능별 직접인력 소요작업량에 계획단위 보정계수(α)를 곱하여 산출한다.

구 분	기준면적	총작업량(인·일)					
		기술사	특 급	고 급	중 급	초 급	보조원
교통성검토	10만㎡	4.2α	12.2α	20.1α	30.5α	40.2α	20.1α

5-5 표준단위 업무분류와 원단위

기술업무의 직능별 직접인력에 의한 소요작업량(10만㎡ 기준)

(단위 : 인·일/표준단위)

업무내용		표준단위	소요인력						비고
			기술사	특 급	고 급	중 급	초 급	보조원	
1.개요	①서론 ②도시·군관리계획 개요	10만㎡ 10만㎡	0.1 0.2	0.3 0.6	0.6 1.2	1.0 2.0	1.2 2.4	0.6 1.2	
	소 계		0.3	0.9	1.8	3.0	3.6	1.8	
2.현황분석	①교통시설 현황분석	10만㎡	1.0	2.4	4.5	8.0	9.0	4.5	
	소 계		1.0	2.4	4.5	8.0	9.0	4.5	
3.교통계획	①교통시설계획 ②교통시설운영계획	10만㎡ 10만㎡	2.5 0.3	8.0 0.6	12.0 1.2	15.5 3.0	24.0 2.4	12.0 1.2	
	소 계		2.8	8.6	13.2	18.5	26.4	13.2	
4.성과품작성	①성과품작성	10만㎡	0.1	0.3	0.6	1.0	1.2	0.6	
	소 계		0.1	0.3	0.6	1.0	1.2	0.6	
총 계			4.2	12.2	20.1	30.5	40.2	20.1	
5.기술협의	①공청회/주민설명회 ②주민간담회/시민계획단 ③위원회심의 지원 ④관계기관 협의	1식 1식 1식 1식	2.0 2.0 2.0 2.0	2.0 2.0 2.0 2.0	2.0 2.0 2.0 2.0	4.0 4.0 4.0 4.0	4.0 4.0 4.0 4.0	4.0 4.0 4.0 4.0	주1
	소 계		8.0	8.0	8.0	16.0	16.0	16.0	

주 : ①기술협의는 2회 이내 기준이며, 횟수가 늘어날 경우 증가배수에 해당하는 작업품과 비용을 가산한다. (필요항목 선택적 적용)

5-6 주요업무내용

구 분	업무내용	내 용
1.개요	①서론	·교통성검토 서론 작성
	②도시·군관리계획 개요	·도시·군관리계획 등 도시계획 개요 작성
2.현황분석	①교통시설 현황분석	·교통시설현황분석, 교통소통현황분석, 교통수단별 운영현황분석
3.교통계획	①교통시설계획	·교통계획지표설정, 기능별 가로망계획, 도로 교차점계획, 기타교통시설계획
	②교통시설운영계획	·도로구조 및 교차로구조개선 등 간선도로망 기능유지, 교통체계관리, 대중교통수단

5-7 표준성과품

성과구분	표준성과도서			비 고
	구 분	규 격	제출부수	
관련도서	1. 교통성검토 기초자료집 2. 교통성검토 보고서	1 식 1 식	3부 50부	

주 : 제출부수 및 성과품 종류가 증가할 경우에는 증가배수에 해당하는 작업품과 비용을 가산한다.

제6절 경관성검토

6-1 정 의

○ 경관성검토는 국토의 계획 및 이용에 관한 법률 제25조 제2항 및 도시·군관리계획수립지침 제6장 도시·군관리계획도서의 작성기준 제2절에 의해 도시·군관리계획을 입안할 때 도시·군관리계획도서를 보조하는 계획설명서에 첨부되는 검토서이다.

○ 경관성 검토는 각종 개발계획에 따른 경관변화를 예측하여 사업시행시 주변 경관에 미치는 영향 등을 검토하여, 경관 및 자연훼손을 최소화하는 방안을 도출 하는데 목적이 있다. 이는 표준품 산정이 책정되어 있지 않은 제11절 도시경관내의 시설경관계획 내용과 같으며, 시설경관계획은 단위시설 및 개별건축에 대한 경관성검토 및 경관계획수립을 말하며 구체적인 경관지침 및 경관개발사업 요소가 포함된다.

6-2 자료제공의 전제

○ 당해 계획의 수립에 필요한 모든 관련 자료는 원칙적으로 발주자가 제공하는 것으로 하되, 발주자가 보유하지 않는 자료는 엔지니어링사업자가 수집한다.

○ 발주자가 제공하지 못하는 자료의 조사에 있어서는 그 규모·내용에 의거하여 별도의 엔지니어링사업대가를 산정하여 엔지니어링사업자가 수행하며, 당해 관련 자료의 기밀성과 광범위한 자료가 요구될 경우는 조사·분석에 필요한 상당기간과 자료수집비용이 전제되어야 한다.

6-3 업무범위와 추진과정

6-3-1 업무범위

○ 경관성검토는 도시의 개발에 따른 경관변화의 분석을 위한 대상지의 경관현황 및 사업의 계획 특성 분석 및 위해 적정 조망점을 선정하고 조망점별 경관시뮬레이션 수행 및 경관종합평가를 통해 주변 경관에 미치는 영향 및 개선방안을 도출하여 도시·군관리계획 입안 시 계획 설명서에 첨부되는 경관성 검토서 작성 등 일련의 과정을 업무범위로 한다.

6-3-2 추진과정

경관성검토 추진과정

경관 현황 조사·분석	·상위계획 및 관련계획검토 ·경관현황자료수집 및 조사 ·종합분석(경관구조, 경관문제 및 잠재력 분석)
사업계획 분석	·사업개요 ·시뮬레이션 여건 분석
조망점 선정	·가시권 분석 ·근경, 중경, 원경을 고려한 조망점 선정
경관시뮬레이션 분석	·주요 조망점에서의 경관시뮬레이션 작성 ·사업 전 · 후 경관비교 및 분석
경관종합평가	·경관영향 요인 분석 ·경관저해요인에 대한 저감방안 수립
성 과 품 작 성	

6-4 품 산정의 원단위 산정과 기준

6-4-1 표준품 산정내역

○ 표준품 산정의 기준이 되는 비목은 제1장 총칙에서 제시한 비목을 중심으로 하였으며, 이는 경관계획수립에 필요한 사항만을 대상으로 한다.

○ 표준품 산정의 기본이 되는 직접인건비 품의 작업항목별 보할은 업무의 난이도를 감안하여 설정토록 한다

종 별		내 용	단 위	비 고
직접비	직접인건비	1.경관현황분석 2.사업계획분석 3.조망점 선정 4.경관시뮬레이션 분석 5.경관영향 분석 및 저감방안 도출 6.성과품 작성 7.기술협의	인·일 〃 〃 〃 〃 〃 〃	
	직접경비	여비, 인쇄비, 조감도, 회의준비비, 현장운영비 등	식	제1장 총칙참조
간접비	제경비	(직접인건비) × 110%	〃	〃
	기술료	(직접인건비+제경비) × 30%	〃	〃

주 : 경관시뮬레이션 제작비는 직접경비로 계상한다.

6-4-2 산정 기준

1. 계획·기준면적의 설정

○ 경관성검토 기준면적은 도시·군관리계획, 단위사업 등 경관성검토 대상지의 규모분포를 분석하여 설정하며, 직능별 직접인력 소요원단위는 기 작성된 계획 등의 투입기술자 비율을 감안하여 설정한다.

2. 표준품의 산정방법

○ 표준품의 적용에 있어 기준면적과 계획면적의 차이에 따른 품 산정은 아래의 수정식에 따라 기준면적의 소요작업량을 수정하여 산정한다.

○ 소요작업량 = 기준면적 소요작업량 × 면적보정계수(α) × 난이도보정계수(β)

3. 검토서의 수정과 과업중지에 따른 품 산정방법

○ 검토서가 작성되고 주민공람, 의회보고 등 행정절차과정을 거쳐 계획안이 확정된 후 발주자의 사정에 의하여 계획안이 일부변경·재작업이 수행되는 경우에는 그 변경·재작업의 정도에 따라 엔지니어링사업대가의 50～100% 수준에서 비용을 추가 지급하여야 한다.

○ 과업수행 중 발주자의 사정에 따른 과업 중단으로 인해 정부 회계연도가 경과되어 현저한 비용의 차이가 발생하였을 경우에는 엔지니어링사업대가를 당해 신년도의 노임단가를 기준으로 재산정하여야 한다.

6-4-3 단위별 변화수정과 보정

1. 작업량 보정계수 산정

1) 면적의 대소에 대한 작업량 보정계수 산정

○ 경관성검토 대상 면적이 기준면적을 초과하거나 이에 못 미치는 경우의 직접인력 소요작업량의 산정을 위한 각 작업내용별 보정계수(α)는 다음과 같이 산정한다.

$$\alpha = (\frac{\text{계획면적}}{\text{기준면적}})^{0.6} = (\frac{A}{1})^{0.6}$$

α = 보정계수
A = 계획면적(만㎡)

계획면적에 대한 작업량 보정계수

계획면적(만㎡)	보정계수(α)	계획면적(만㎡)	보정계수(α)
0.5	0.659	7.0	3.214
1.0	1.000	10.0	3.981
2.0	1.515	15.0	5.077
3.0	1.933	20.0	6.034
5.0	2.626	30.0	7.696

주 : 계획면적이 0.5만㎡ 미만인 경우에는 계획면적 0.5만㎡을 기준으로 하여 산정한다.

2) 계획성격에 따른 난이도 보정계수 산정

○ 계획의 특성에 따라 난이도 보정계수를 적용하여 산정한다.

유형특성에 따른 보정계수

구 분	유형특성 보정계수(β)
1.단위시설형(단일 개별 시설이나 복수의 개별시설)	1.00
2.면적 개발이나 용도지역의 변경(지역, 구역 등의 면적 대상지나 용도지역의 변경)	0.50

2. 직접인건비 소요 작업량 산정

○ 계획면적의 대소에 따른 직접인력 소요작업량의 산정방법은 아래와 같이 기준면적의 직능별 직접인력 소요작업량에 계획단위 보정계수(α, β)를 곱하여 산출한 값에 기술협의 값을 더하여 산출한다.

구 분	기준면적 (만㎡)	총작업량 (인·일)					
		기술사	특 급	고 급	중 급	초 급	보조원
경관성검토	1.0	6.1αβ	9.2αβ	11.0αβ	16.9αβ	20.8αβ	22.3αβ

6-5 표준단위 업무분류와 원단위

기술업무의 직능별 직접인력 소요작업량 (면적 1만㎡ 기준)

(단위 : 인·일/표준단위)

업무내용		표준단위	소요인력						비고
			기술사	특급	고급	중급	초급	보조원	
1.경관현황분석	①현황조사	1만㎡	0.1	0.2	0.4	0.8	1.0	1.5	
	②관련법규 · 계획 검토	1만㎡	0.1	0.2	0.4	0.6	0.9	1.3	
	③현황종합분석	1만㎡	0.2	0.2	0.4	0.6	0.9	1.2	
	소 계		0.4	0.6	1.2	2.0	2.8	4.0	
2.사업계획분석	①사업개요	1만㎡	0.1	0.2	0.4	0.6	1.0	1.0	
	②시뮬레이션 여건	1만㎡	0.1	0.2	0.4	0.6	1.0	1.0	
	소 계		0.2	0.4	0.8	1.2	2.0	2.0	
3.조망점 선정	①예비조망점 선정	1만㎡	0.1	0.2	0.4	0.7	0.9	1.2	
	②가시권분석	1만㎡	0.1	0.2	0.4	0.8	1.0	1.5	
	③최종조망점 선정	1만㎡	0.2	0.2	0.4	0.5	0.9	1.3	
	소 계		0.4	0.6	1.2	2.0	2.8	4.0	
4.경관시뮬레이션 분석	①조망점별 시뮬레이션 분석	1만㎡	0.8	1.4	2.2	3.6	4.5	4.9	주1
	②시뮬레이션 종합분석	1만㎡	1.2	1.8	1.8	1.6	1.5	1.1	
	소 계		2.0	3.2	4.0	5.2	6.0	6.0	
5.경관영향 분석 및 저감방안 도출	①경관예측	1만㎡	1.4	2.0	1.4	2.4	2.6	2.0	
	②저감방안 수립	1만㎡	1.4	2.0	1.4	2.4	2.6	2.0	
	소 계		2.8	4.0	2.8	4.8	5.2	4.0	
6.성과품 작성	①보고서 작성 및 편집	1만㎡	0.2	0.2	0.5	0.9	1.0	1.2	
	②관련도서 작성	1만㎡	0.1	0.2	0.5	0.8	1.0	1.1	
	소 계		0.3	0.4	1.0	1.7	2.0	2.3	
총 계			6.1	9.2	11.0	16.9	20.8	22.3	
7.기술협의	①공청회/주민설명회	1식	2.0	2.0	2.0	4.0	4.0	4.0	주2
	②주민간담회/시민계획단	1식	2.0	2.0	2.0	4.0	4.0	4.0	
	③위원회심의 지원	1식	2.0	2.0	2.0	4.0	4.0	4.0	
	④관계기관 협의	1식	2.0	2.0	2.0	4.0	4.0	4.0	
	소 계		8.0	8.0	8.0	16.0	16.0	16.0	

주 : ①경관시뮬레이션에 필요한 컴퓨터 그래픽 제작비용은 직접경비로 별도 계산한다.

②기술협의는 2회 이내 기준이며, 횟수가 늘어날 경우 증가배수에 해당하는 작업품과 비용을 가산한다. (필요항목 선택적 적용)

6-6 주요업무내용

구 분	내 용
1.경관현황분석	·경관성검토를 작성하기 위한 계획구역안의 경관요소현황, 토지의 이용상황, 기타 필요한 사항의 조사 ·경관관련 상위계획, 기존계획, 조치사항 분석 등 ·경관현황종합분석
2.사업계획분석	·사업개요 ·시뮬레이션 여건 : 경관목표, 방향 및 주제, 경관구조분석, 경관문제 및 잠재력 분석, 보전 및 개선 대상지 선정
3.조망점 선정	·조망대상 및 경관축 검토 ·예비조망점 선정 ·가시권 분석 ·최종 주요 경관 시뮬레이션 조망점 선정
4.경관시뮬레이션 분석	·조망점별 시뮬레이션 분석 : 시뮬레이션 방향별, 시거리별(근경, 중경, 원경)경관효과 검증 및 주요표현 내용 설정 ·작성 시뮬레이션의 검토 (시뮬레이션 제작비는 직접경비로 계상) ·시뮬레이션 종합검토
5.경관영향 분석 및 저감방안 도출	·경관예측 ·저감방안 수립

6-7 표준성과품

성과구분	표준성과도서			비 고
	구 분	규 격	제출부수	
현황분석도	·경관현황분석도	1/25,000이상	1부	
보고서	·경관성검토 보고서		1부	
CD	·자료CD		1식	

주 : ①제출부수 및 성과품 종류가 증가할 경우에는 증가배수에 해당하는 작업품과 비용을 가산한다.
②계획보고서 및 기타 관련자료의 규격 및 제출부수는 발주자와의 협의에 의하여 비용을 산정한다.

제7절 사전재해영향성검토

7-1 정 의

○ 사전재해영향성검토 협의는 관계행정기관의 장이 자연재해에 영향을 미치는 행정계획을 수립·확정하거나 개발사업의 허가·인가·승인·면허·결정·지정 등을 하는 경우 미리 재해위험(유발)요인을 조사·검토·분석 등을 통하여 재해경감대책을 마련하여 중앙재난안전대책본부장 및 지역재난안전대책본부장에게 협의하고, 협의 결과를 각종 행정계획 및 개발계획에 반영하여 자연재해를 예방 및 경감하고자 하는 것으로, 사전재해영향성 검토서는 관련계획의 검토 및 현황조사 등의 기초조사와 재해영향 예측, 재해영향에 대한 저감대책수립, 향후 이행 및 관리계획 등의 내용을 체계적으로 정리하여 작성하여야 한다.

7-2 자료제공의 전제

○ 사전재해영향성검토 협의에 필요한 모든 관련자료는 원칙적으로 발주자가 제공하는 것으로 하되, 발주자가 보유하지 않은 자료는 대행자가 수집한다.

○ 발주자가 제공하지 못하는 자료 등의 조사를 위하여 필요한 경우 그 규모·내용에 따라 별도의 대가를 산정하여 방재안전대책수립 대행자에게 수행하도록 할 수 있으며, 해당 관련 자료의 기밀성과 광범위한 자료가 요구되는 경우 조사·분석에 필요한 상당기간과 자료수집 비용이 전제되어야 한다.

7-3 업무범위와 추진과정

7-3-1 업무범위

○ 「자연재해대책법 시행령」제3조에 따른 “사전재해영향성검토 협의 내용에 포함되어야 할 사항”과 중앙재난안전대책본부장이 고시한「사전재해영향성검토 협의 중점 검토항목 및 방법 등에 관한 사항 고시」의 업무내용을 충족하여야 한다.

○ 「방재분야 표준품셈 」내 “사전재해영향성검토”표준품셈이 본 품셈과 다를 경우 「방재분야 표준품셈 」을 따른다.

7-3-2 추진과정

1. 협의절차

○ 개발사업을 하고자 하는 행정기관 또는 사업자는 재해에 관한 영향을 검토한 내용이

포함된 해당 사업계획서를 승인기관에 제출한다.

○ 행정기관 또는 사업자로부터 사업계획서를 접수받은 사업승인기관의장(관계중앙행정기관의 장, 시 · 도지사, 시장 · 군수 · 구청장 등)은 자연재해에 영향을 미치는 행정계획을 수립 · 확정(지역 · 지구 · 단지 등의 지정 포함)하거나 개발사업을 허가 · 인가 · 승인 · 면허 · 결정 · 지정 등을 하기 전에 중앙재난안전대책본부장 또는 지역재난안전대책본부장에게 협의를 요청한다.

○ 사업승인기관으로부터 재해영향에 관한 협의요청을 받은 중앙 및 지역 본부장은 개발관련 행정계획 또는 개발사업이 협의대상사업의 범위에 해당하는 지와 협의시기가 적정한지 등의 기본요건을 검토하고,

○ 중앙 또는 지역본부장은 행정계획 및 개발사업의 협의요청 시 포함된 재해예방 및 저감대책 등을 관련부서와 사전재해영향성검토위원회의 의견을 종합하여 검토한다.

○ 중앙 또는 지역본부장으로부터 협의결과를 통보받은 관계 행정기관의 장은 특별한 사유가 없는 한 통보를 받은 날로부터 30일(「산업집적 활성화 및 공장설립에 관한 법률」제13조에 따른 공장설립 등의 승인의 경우에는 20일) 이내 해당 행정계획 또는 개발계획에 협의결과를 검토·반영한 조치결과 또는 조치계획을 중앙 또는 지역본부장에게 통보하여야 한다.

협의절차

사전재해영향성 검토서 제출	⇒	협의요청	⇒	사전재해영향성검토협의	⇒
사업시행자→관계행정기관		관계행정기관→중앙/지역본부		중앙/지역본부	

검토결과의 통보	⇒	조치결과 및 계획통보
중앙/지역본부→관계행정기관		관계행정기관→중앙/지역본부

2. 과업수행 추진과정

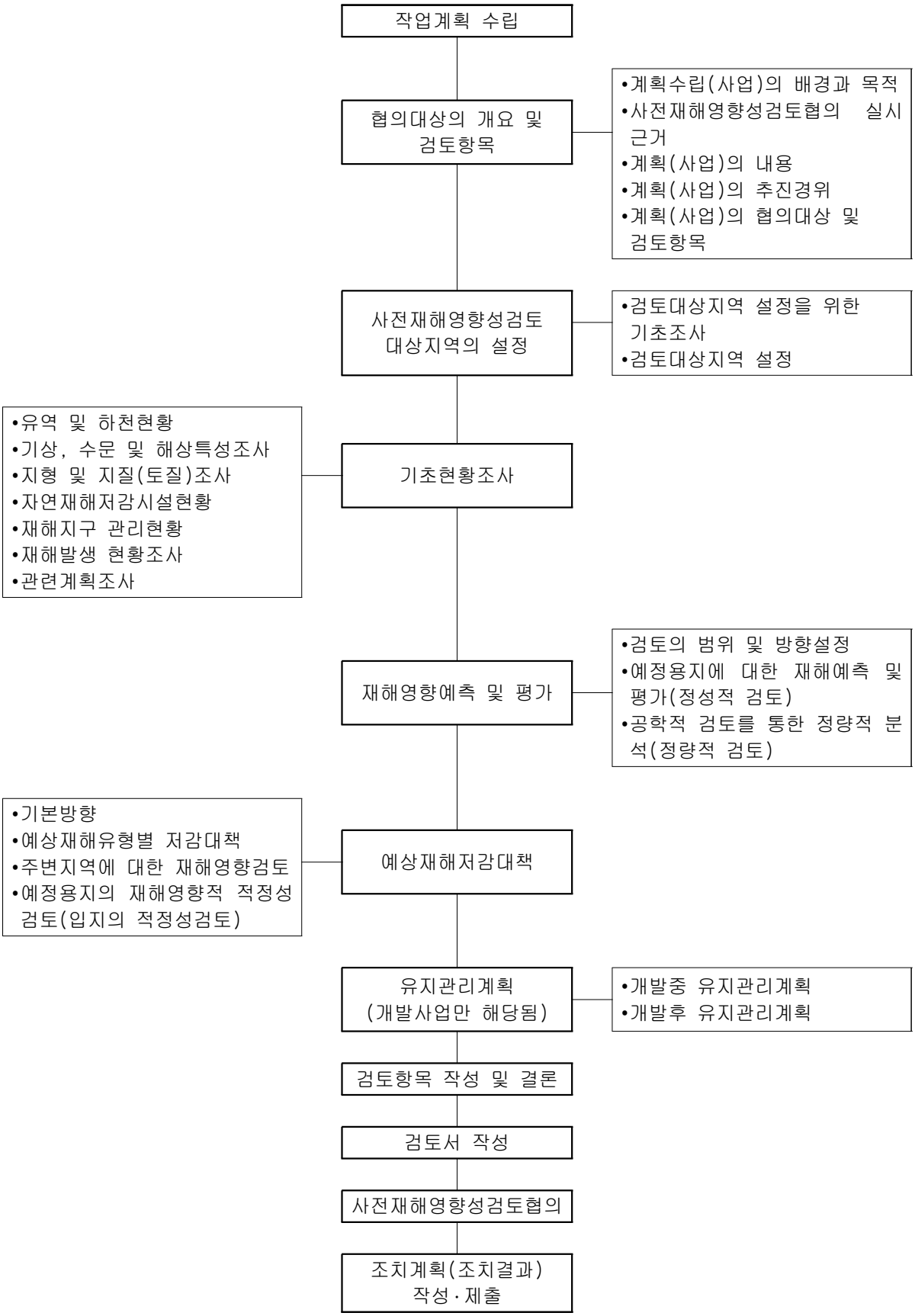
작업계획 수립
협의대상의 개요 및 검토항목
•계획수립(사업)의 배경과 목적
•사전재해영향성검토협의 실시 근거
•계획(사업)의 내용
•계획(사업)의 추진경위
•계획(사업)의 협의대상 및 검토항목
사전재해영향성검토 대상지역의 설정
•검토대상지역 설정을 위한 기초조사
•검토대상지역 설정
기초현황조사
•유역 및 하천현황
•기상, 수문 및 해상특성조사
•지형 및 지질(토질)조사
•자연재해저감시설현황
•재해지구 관리현황
•재해발생 현황조사
•관련계획조사
재해영향예측 및 평가
•검토의 범위 및 방향설정
•예정용지에 대한 재해예측 및 평가(정성적 검토)
•공학적 검토를 통한 정량적 분석(정량적 검토)
예상재해저감대책
•기본방향
•예상재해유형별 저감대책
•주변지역에 대한 재해영향검토
•예정용지의 재해영향적 적정성 검토(입지의 적정성검토)
유지관리계획 (개발사업만 해당됨)
•개발중 유지관리계획
•개발후 유지관리계획
검토항목 작성 및 결론
검토서 작성
사전재해영향성검토협의
조치계획(조치결과) 작성·제출

7-4 품 산정의 원단위 산정과 기준

7-4-1 표준품 산정내역

○ 표준품 산정의 기준이 되는 비목은 제1장 총칙에서 제시한 비목을 적용하고 직접인건비는 사전재해영향성검토 업무의 소요인력 표준 원단위 기준과 보정계수를 적용하여 계상한다.

1. 행정계획(시·군·구 단위이상계획)

종 별		내 용	세부항목	단위	비 고
직접비	직접인건비	1.작업계획	①작업계획 수립	인·일	
		2.협의대상의 개요 및 검토 항목	①계획수립의 배경과 목적 ②사전재해영향성검토협의 실시근거 ③계획의 내용 ④계획의 추진경위 ⑤계획의 협의대상 및 검토항목	〃 〃 〃 〃 〃	
		3.사전재해영향성검토 대상지역의 설정	①검토대상지역설정을 위한 기초조사 ②검토대상지역의 설정	〃 〃	
		4.기초현황조사	①유역 및 하천현황 ②기상, 수문 및 해상특성조사 ③지형 및 지질조사 ④자연재해저감시설 현황 ⑤재해지구 관리현황 ⑥재해발생현황조사 ⑦관련계획조사	〃 〃 〃 〃 〃 〃 〃	
		5.재해영향예측 및 평가	①검토의 범위 및 방향설정 ②예정용지에 대한 재해예측 및 평가	〃 〃	보정계수적용
		6.예상재해 저감대책	①기본방향 ②예상재해유형별 저감대책 ③주변지역에 대한 재해영향검토 ④입지의 적정성검토	〃 〃 〃 〃	보정계수적용 보정계수적용
		7.검토항목 작성 및 결론	①검토항목 작성 ②결론	〃 〃	
		8.검토서 작성	①검토서 작성	〃	
	직접경비	여비, 인쇄비, 조감도, 회의준비비, 현장운영비 등		식	제1장 총직참조
간접비	제경비	(직접인건비) × 115%		〃	
	기술료	(직접인건비+제경비) × 30%		〃	

2. 행정계획(일반사업계획)

종 별		내 용	세부항목	단위	비 고
직접비	직접인건비	1.작업계획	①작업계획 수립	인·일	
		2.협의대상의 개요 및 검토 항목	①계획수립의 배경과 목적 ②사전재해영향성검토협의 실시근거 ③계획의 내용 ④계획의 추진경위 ⑤계획의 협의대상 및 검토항목	〃 〃 〃 〃 〃	
		3.사전재해영향성검토 대상지역의 설정	①검토대상지역설정을 위한 기초조사 ②검토대상지역의 설정	〃 〃	보정계수적용 보정계수적용
		4.기초현황조사	①유역 및 하천현황 ②기상, 수문 및 해상특성조사 ③지형 및 지질조사 ④자연재해저감시설 현황 ⑤재해지구 관리현황 ⑥재해발생현황조사 ⑦관련계획조사	〃 〃 〃 〃 〃 〃 〃	보정계수적용 보정계수적용 보정계수적용 보정계수적용 보정계수적용 보정계수적용
		5.재해영향예측 및 평가	①검토의 범위 및 방향설정 ②예정용지에 대한 재해예측 및 평가 ③공학적 검토를 통한 정량적 분석(필요시)	〃 〃 〃	보정계수적용 보정계수적용
		6.예상재해 저감대책	①기본방향 ②예상재해유형별 저감대책 ③주변지역에 대한 재해영향검토 ④입지의 적정성검토	〃 〃 〃 〃	보정계수적용 보정계수적용
		7.검토항목 작성 및 결론	①검토항목 작성 ②결론	〃 〃	
		8.검토서 작성	①검토서 작성	〃	
	직접경비	여비, 인쇄비, 조감도, 회의준비비, 현장운영비 등		식	제1장 총직참조
간접비	제경비	(직접인건비) × 115%		〃	
	기술료	(직접인건비+제경비) × 30%		〃	

3. 개발사업

종 별		내 용	세부항목	단위	비 고
직접비	직접인건비	1.작업계획	①작업계획 수립	인·일	
		2.협의대상의 개요 및 검토 항목	①사업의 배경과 목적 ②사전재해영향성검토협의 실시근거 ③사업의 내용 ④사업의 추진경위 ⑤사업의 협의대상 및 검토항목	〃 〃 〃 〃 〃	
		3.사전재해영향성검토 대상 지역의 설정	①검토대상지역설정을 위한 기초조사 ②검토대상지역의 설정	〃 〃	보정계수적용 보정계수적용
		4.기초현황조사	①유역 및 하천현황 ②기상, 수문 및 해상특성조사 ③지형 및 토질조사 ④자연재해저감시설 현황 ⑤재해지구 관리현황 ⑥재해발생현황조사 ⑦관련계획조사	〃 〃 〃 〃 〃 〃 〃	보정계수적용 보정계수적용 보정계수적용 보정계수적용 보정계수적용 보정계수적용
		5.재해영향예측 및 평가	①검토의 범위 및 방향설정 ②예정용지에 대한 재해예측 및 평가 ③공학적 검토를 통한 정량적 분석	〃 〃 〃	보정계수적용 보정계수적용
		6.예상재해 저감대책	①기본방향 ②예상재해유형별 저감대책 ③주변지역에 대한 재해영향검토 ④예정용지의 재해영향적 적정성검토	〃 〃 〃 〃	보정계수적용 보정계수적용
		7.유지관리계획	①개발중 유지관리계획 ②개발후 유지관리계획	〃 〃	
		8.검토항목 작성 및 결론	①검토항목 작성 ②결론	〃 〃	
		9.검토서 작성	①검토서 작성	〃	
	직접경비	여비, 인쇄비, 조감도, 회의준비비, 현장운영비 등		식	제1장 총직참조
간접비	제경비	(직접인건비) × 115%		〃	
	기술료	(직접인건비+제경비) × 30%		〃	

7-4-2 산정기준

1. 계획·기준면적 선정

○ 행정계획 중 시・군・구 단위이상 계획은 행정구역면적 100㎢를 기준수량으로 적용하여 책정한다.

○ 행정계획 중 일반사업계획은 계획(사업)대상 면적 및 연장에 대하여 각각 100,000㎡, 10km를 기준수량으로 적용하여 책정한다.

○ 개발사업은 계획(사업)대상 면적 및 연장에 대하여 각각 100,000㎡, 10km를 기준수량으로 적용하여 책정한다.

2. 표준품의 산정방법

○ 표준품의 적용에 있어 기준면적과 과업면적의 차이에 따른 품 산정은 아래의 수정식에 따라 기준면적의 소요작업량을 수정하여 산정한다.

○ 소요작업량 = 기준면적 소요작업량 × 면적보정계수(α)

3. 계획안의 수정과 과업중지에 따른 품 산정방법

○ 계획안이 작성되고 주민공람, 의회보고 등 행정절차과정을 거쳐 계획안이 확정된 후 발주자의 사정에 의하여 계획안이 일부변경·재작업이 수행되는 경우에는 그 변경·재작업의 정도에 따라 엔지니어링사업대가의 50～100% 수준에서 비용을 추가 지급하여야 한다.

○ 과업수행 중 발주자의 사정에 따른 과업 중단으로 인해 정부 회계연도가 경과되어 현저한 비용의 차이가 발생하였을 경우에는 엔지니어링사업대가를 당해 신년도의 노임단가를 기준으로 재산정하여야 한다.

7-4-3 단위별 변화수정과 보정

1. 작업량 보정계수 산정

1) 행정계획(시・군・구단위이상계획)

○ 행정구역면적을 적용기준으로 하는 표준원단위가 100㎢를 기준으로 산정되었으므로 행정구역면적의 대소에 따라 다음의 산식으로 보정계수를 산정하여 단위업무별 소요인력량을 보정한다.

$$\alpha 1 = (\frac{A}{100})^{0.25}$$

α_1 = 보정계수
A = 계획면적(㎢)

2) 행정계획(일반사업계획)

○ 계획(사업)대상규모를 적용기준으로 하는 표준원단위가 면적 10만㎡, 연장 10km를 기준으로 산정되었으므로 계획(사업)대상규모에 따라 다음의 산식으로 보정계수를 산정하여 단위업무별 소요인력량을 보정한다.

○ 면적 10만㎡(연장 10 km) 이상인 경우 $\alpha_2 = (\frac{A}{10})^{0.25}$

○ 면적 10만㎡(연장 10 km) 미만인 경우 $\alpha_3 = (\frac{A}{10})^{0.50}$

∴ A : 계획대상규모(㎡, km), α_2, α_3 : 보정계수

※사업대상지가 복수인 경우 대상지별로 각각 산정한 후 합산한다.

3) 개발사업

○ 계획(사업)대상규모를 적용기준으로 하는 표준원단위가 면적 10만㎡, 연장 10km를 기준으로 산정되었으므로 계획(사업)대상규모에 따라 다음의 산식으로 보정계수를 산정하여 단위업무별 소요인력량을 보정한다.

○ 면적 10만㎡(연장 10 km) 이상인 경우 $\alpha 4 = (\frac{A}{10})^{0.25}$

○ 면적 10만㎡(연장 10 km) 미만인 경우 $\alpha_5 = (\frac{A}{10})^{0.50}$

∴ A : 계획(사업)대상규모(㎡, km), α_4, α_5 : 보정계수

※사업대상지가 복수인 경우 대상지별로 각각 산정한 후 합산한다.

2. 직접인건비 소요 작업량 산정

○ 사전재해영향성 검토 협의를 위한 단위업무별 소요인력은 다음과 같다.

구 분	기준면적 (㎢)	소요인력 (인 · 일)					
		기술사	특 급	고 급	중 급	초 급	보조원
행정계획 (시·군·구 단위 이상계획)	100	9.80α (10.80)	14.90α (16.25)	22.20α (24.60)	26.05α (28.80)	27.90α (29.90)	20.25α (21.75)
행정계획 (일반사업계획)	10	5.15α (7.35)	7.85α (10.85)	12.25α (16.20)	14.95α (20.55)	17.85α (24.90)	12.45α (16.85)
개발사업	10	14.45α (16.85)	22.50α (26.30)	34.75α (41.40)	45.05α (52.50)	52.20α (56.90)	33.35α (36.40)

주 : ()안은 연안재해·바람재해·기타재해를 포함하였을 때의 합계임

7-5 표준단위 업무분류와 원단위

1. 행정계획(시·군·구 단위 이상계획)

기술업무의 직능별 직접인력 소요작업량 (100㎢ 기준)

(단위 : 인·일/표준단위)

구 분	업무내용	표준단위	소요인력						비 고
			기술사	특급	고급	중급	초급	보조원	
1.작업계획	①작업계획 수립	100㎢	0.10	0.20	0.20	0.10	-	-	
2.협의대상의 개요 및 검토항목	①계획수립의 배경과 목적	100㎢	-	-	0.03	0.03	0.05	0.05	
	②사전재해영향성검토협의 실시근거	100㎢	-	-	0.02	0.02	0.05	0.05	
	③계획의 내용	100㎢	-	-	0.10	0.10	0.25	0.25	
	④계획의 추진경위	100㎢	-	-	0.02	0.02	0.05	0.05	
	⑤계획의 협의대상 및 검토항목	100㎢	-	-	0.03	0.03	0.10	0.10	
3.사전재해영향성 검토 대상지역의 설정	①검토대상지역설정을 위한 기초조사	100㎢	0.40	1.10	1.20	1.10	1.30	0.80	
	②검토대상지역의 설정	100㎢	0.20	0.70	0.90	0.60	0.70	0.40	
4.기초현황조사	①유역 및 하천현황	100㎢	0.70	0.80	1.40	1.80	1.70	1.70	
	②기상, 수문 및 해상특성조사	100㎢	0.40 (0.60)	0.50 (0.75)	1.00 (1.30)	1.00 (1.45)	1.20 (1.80)	1.10 (1.70)	
	③지형 및 지질조사	100㎢	0.30	0.60	1.00	1.40	1.00	1.80	
	④자연재해저감시설 현황	100㎢	0.15	0.20	0.30	0.40	0.60	0.55	
	⑤재해지구 관리현황	100㎢	0.20	0.20	0.30	0.60	0.40	0.40	
	⑥재해발생현황조사	100㎢	0.50	0.80	0.70	1.50	1.40	1.40	
	⑦관련계획조사	100㎢	0.30	0.40	0.60	0.80	0.70	1.10	
5.재해영향예측 및 평가	①검토의 범위 및 방향설정	100㎢	0.10	0.10	0.20	0.30	0.40	0.30	
	②예정용지에 대한 재해예측 및 평가	100㎢	2.80 (3.30)	3.90 (4.60)	4.50 (5.50)	6.10 (7.30)	9.20 (10.20)	5.00 (5.60)	보정계수적용
6.예상재해 저감대책	①기본방향	100㎢	0.10	0.10	0.20	0.30	0.40	0.30	
	②예상재해유형별 저감대책	100㎢	1.10 (1.40)	2.00 (2.40)	5.00 (6.10)	5.00 (6.10)	3.00 (3.40)	1.60 (1.90)	보정계수적용
	③주변지역에 대한 재해영향검토	100㎢	0.30	0.30	0.30	0.60	0.90	0.75	보정계수적용
	④입지의 적정성검토	100㎢	0.75	1.05	1.35	1.80	2.55	2.55	
7.검토항목 작성 및 결론	①검토항목 작성	100㎢	0.80	0.80	1.60	1.60	1.60	-	
	②결론	100㎢	0.10	0.15	0.25	0.35	0.35	-	
8.검토서 작성	①검토서 작성	100㎢	0.50	1.00	1.00	0.50	0.00	-	
합 계			9.80 (10.80)	14.90 (16.25)	22.20 (24.60)	26.05 (28.80)	27.90 (29.90)	20.25 (21.75)	

주 : ()안은 연안재해·바람재해·기타재해를 포함하였을 때의 합계임

2. 행정계획(일반사업계획)

기술업무의 직능별 직접인력 소요작업량 (10만㎡, 연장 10㎞ 기준)

(단위 : 인·일/표준단위)

구 분	업무내용	표준단위	소요인력						비 고
			기술사	특급	고급	중급	초급	보조원	
1.작업계획	①작업계획 수립	10만㎡외	0.10	0.20	0.20	0.10	0.00	0.00	
2.협의대상의 개요 및 검토 항목	①계획수립의 배경과 목적	10만㎡외	0.00	0.00	0.03	0.03	0.05	0.05	
	②사전재해영향성검토협의 실시근거	10만㎡외	0.00	0.00	0.02	0.02	0.05	0.05	
	③계획의 내용	10만㎡외	0.00	0.00	0.10	0.10	0.25	0.25	
	④계획의 추진경위	10만㎡외	0.00	0.00	0.02	0.02	0.05	0.05	
	⑤계획의 협의대상 및 검토항목	10만㎡외	0.00	0.00	0.03	0.03	0.10	0.10	
3.사전재해영향성검토 대상지역의 설정	①검토대상지역설정을 위한 기초조사	10만㎡외	0.20	0.55	0.60	0.80	0.90	0.40	보정계수적용
	②검토대상지역의 설정	10만㎡외	0.10	0.35	0.45	0.55	0.60	0.20	보정계수적용
4.기초현황조사	①유역 및 하천현황	10만㎡외	0.35	0.40	0.70	0.90	1.35	1.35	보정계수적용
	②기상, 수문 및 해상특성조사	10만㎡외	0.40 (0.60)	0.50 (0.75)	1.00 (1.30)	1.00 (1.45)	1.20 (1.80)	1.10 (1.70)	
	③지형 및 지질조사	10만㎡외	0.15	0.30	0.50	0.70	1.00	0.90	보정계수적용
	④자연재해저감시설 현황	10만㎡외	0.15	0.20	0.30	0.40	0.60	0.55	보정계수적용
	⑤재해지구 관리현황	10만㎡외	0.10	0.10	0.15	0.30	0.20	0.20	
	⑥재해발생현황조사	10만㎡외	0.25	0.40	0.60	0.75	1.20	1.20	보정계수적용
	⑦관련계획조사	10만㎡외	0.10	0.20	0.30	0.40	0.60	0.55	보정계수적용
5.재해영향예측 및 평가	①검토의 범위 및 방향설정	10만㎡외	0.10	0.10	0.20	0.30	0.40	0.30	
	②예정용지에 대한 재해예측 및 평가	10만㎡외	1.40 (1.70)	1.95 (2.40)	2.25 (2.85)	3.55 (4.25)	5.10 (5.70)	3.00 (3.35)	보정계수적용
	③공학적 검토를 통한 정량적 분석(필요시)	10만㎡외	(1.50)	(2.05)	(2.40)	(3.80)	(5.60)	(3.25)	보정계수적용
6.예상재해 저감대책	①기본방향	10만㎡외	0.10	0.10	0.20	0.30	0.40	0.30	
	②예상재해유형별 저감대책	10만㎡외	0.55 (0.75)	1.00 (1.25)	2.50 (3.15)	2.50 (3.15)	1.50 (1.75)	0.80 (1.00)	보정계수적용
	③주변지역에 대한 재해영향검토	10만㎡외	0.10	0.10	0.10	0.20	0.30	0.25	보정계수적용
	④입지의 적정성검토	10만㎡외	0.25	0.35	0.45	0.60	0.85	0.85	
7.검토항목 작성 및 결론	①검토항목 작성	10만㎡외	0.40	0.40	0.80	0.80	0.80	0.00	
	②결론	10만㎡외	0.10	0.15	0.25	0.35	0.35	0.00	
8.검토서 작성	①검토서 작성	10만㎡외	0.25	0.50	0.50	0.25	0.00	0.00	
합 계			5.15 (7.35)	7.85 (10.85)	12.25 (16.20)	14.95 (20.55)	17.85 (24.90)	12.45 (16.85)	

주 : ()안은 연안재해·바람재해·기타재해를 포함하였을 때의 합계임

3. 개발사업

기술업무의 직능별 직접인력 소요작업량 (10만㎡, 연장 10㎞ 기준)

(단위 : 인·일/표준단위)

구 분	업무내용	표준단위	소요인력						비 고
			기술사	특급	고급	중급	초급	보조원	
1.작업계획	①작업계획 수립	10만㎡외	0.10	0.20	0.20	0.10	0.00	0.00	
2.협의대상의 개요 및 검토 항목	①사업의 배경과 목적	10만㎡외	0.00	0.00	0.03	0.03	0.05	0.05	
	②사전재해영향성검토협의 실시근거	10만㎡외	0.00	0.00	0.02	0.02	0.05	0.05	
	③사업의 내용	10만㎡외	0.00	0.00	0.10	0.10	0.25	0.25	
	④사업의 추진경위	10만㎡외	0.00	0.00	0.02	0.02	0.05	0.05	
	⑤사업의 협의대상 및 검토항목	10만㎡외	0.00	0.00	0.03	0.03	0.10	0.10	
3.사전재해영향성 검토 대상 지역의 설정	①검토대상지역설정을 위한 기초조사	10만㎡외	0.20	0.55	0.60	0.80	0.90	0.40	보정계수적용
	②검토대상지역의 설정	10만㎡외	0.10	0.35	0.45	0.55	0.60	0.20	보정계수적용
4.기초현황조사	①유역 및 하천현황	10만㎡외	0.35	0.40	0.70	0.90	1.35	1.35	보정계수적용
	②기상, 수문 및 해상특성조사	10만㎡외	0.40 (0.60)	0.50 (0.75)	1.00 (1.30)	1.00 (1.45)	1.20 (1.80)	1.10 (1.70)	
	③지형 및 토질조사	10만㎡외	0.25	0.40	0.65	0.90	1.35	1.20	보정계수적용
	④자연재해저감시설 현황	10만㎡외	0.15	0.20	0.30	0.40	0.60	0.55	보정계수적용
	⑤재해지구 관리현황	10만㎡외	0.10	0.10	0.15	0.30	0.20	0.20	
	⑥재해발생현황조사	10만㎡외	0.25	0.40	0.60	0.75	1.20	1.20	보정계수적용
	⑦관련계획조사	10만㎡외	0.10	0.20	0.30	0.40	0.60	0.55	보정계수적용
5.재해영향 예측 및 평가	①검토의 범위 및 방향설정	10만㎡외	0.10	0.10	0.20	0.30	0.40	0.30	
	②예정용지에 대한 재해예측 및 평가	10만㎡외	1.30 (1.60)	1.90 (2.35)	2.20 (2.75)	3.50 (4.20)	5.00 (5.55)	3.00 (3.30)	보정계수적용
	③공학적 검토를 통한 정량적 분석	10만㎡외	6.50 (7.85)	9.50 (11.55)	11.00 (13.75)	17.50 (20.80)	25.00 (27.75)	14.80 (16.45)	보정계수적용
6.예상재해 저감대책	①기본방향	10만㎡외	0.10	0.10	0.20	0.30	0.40	0.30	
	②예상재해유형별 저감대책	10만㎡외	2.30 (2.85)	4.35 (5.40)	12.15 (15.20)	12.15 (15.15)	7.30 (8.10)	3.65 (4.15)	보정계수적용
	③주변지역에 대한 재해영향검토	10만㎡외	0.15	0.20	0.20	0.40	0.60	0.55	보정계수적용
	④예정용지의 재해영향적 적정성검토	10만㎡외	0.50	0.70	0.90	1.25	1.75	1.70	
7.유지관리계획	①개발중 유지관리계획	10만㎡외	0.25	0.40	0.35	0.85	1.05	0.90	
	②개발후 유지관리계획	10만㎡외	0.25	0.40	0.35	0.85	1.05	0.90	
8.검토항목 작성 및 결론	①검토항목 작성	10만㎡외	0.40	0.40	0.80	0.80	0.80	0.00	
	②결론	10만㎡외	0.10	0.15	0.25	0.35	0.35	0.00	
9.검토서 작성	①검토서 작성	10만㎡외	0.50	1.00	1.00	0.50	0.00	0.00	
합 계			14.45 (16.85)	22.50 (26.30)	34.75 (41.40)	45.05 (52.50)	52.20 (56.90)	33.35 (36.40)	

주 : ()안은 연안재해·바람재해·기타재해를 포함하였을 때의 합계임

7-6 주요업무내용

1. 행정계획(시·군·구 단위이상계획)

구 분	업무내용	내 용
1.작업계획수립	①작업계획수립	•분야별 작업계획수립 및 협조체계 구축 •자료수집 및 조사일정 수립 •인력투입 및 예정공정표 작성 •기타 과업수행에 필요한 제반사항 검토
2.협의대상의 개요 및 검토항목	①계획수립의 배경과 목적	•계획수립의 배경 •계획의 필요성과 목적
	②사전재해영향성검토 협의 실시 근거	•대상사업의 종류 및 범위 •관련법, 행정계획의 범위, 협의시기
	③계획의 내용	•계획의 명칭, 위치, 면적, 승인기관 •계획대상지 위치도 •계획지구 현장사진
	④계획의 추진경위	•인·허가 절차 및 향후 추진계획
	⑤계획의 협의대상 및 검토항목	•협의대상 및 개요, 협의절차 •공통사항, 입지유형별, 협의대상 유형별 검토항목
3.사전재해영향성검토 대상지역의 설정	①검토대상지역설정을 위한 기초조사	•현지조사, 문헌조사 •관련계획조사
	②검토대상지역 설정	•검토대상지역 설정
4.기초현황조사	①유역 및 하천현황	•유역 일반현황조사 •대상유역의 경사, 면적, 유로연장, 형상계수조사 •대상유역 내·외의 하천현황, 하천등급, 하천특성, 유로방향조사 •하천의 계획홍수위, 제방고, 개수현황 및 정비상태조사 •대상유역의 토지이용현황 •대상유역의 유수흐름 및 배수계통도
	②기상, 수문 및 해상특성조사	•관측소(기상, 수문, 해상) 현황조사 •관측자료 수집 및 정리
	③지형 및 지질조사	•경사 및 표고 현황조사 •토양 및 지표지질도 조사
	④자연재해저감시설현황	•자연재해저감시설물 조사 •시설물의 노후화 상태, 기능(작동) 상태 등의 운영 및 관리 평가
	⑤재해지구 관리현황	•재해위험지역조사 •재해위험지구지정 현황도 작성
	⑥재해발생 현황조사	•문헌조사(연도별, 기간별 피해현황조사) •탐문조사
	⑦관련계획조사	•상위계획 및 관련계획조사 •주변지역 개발계획조사

구 분	업무내용	내 용
5.재해영향예측 및 평가	①검토의 범위 및 방향 설정	•재해유형별 검토범위 설정 •재해예측 및 분석방향 설정
	②예정용지에 대한 재해예측 및 평가	•정성적 검토 •하천재해, 호우재해, 사면재해, 지반재해, 연안재해, 바람재해, 기타재해
6.예상재해저감대책	①기본방향	•사업시행으로 인한 문제점 •재해저감방향
	②예상재해유형별 저감대책	•사업시행전 사전조치 •개발중, 후 재해저감대책수립 •하천재해, 호우재해, 사면재해, 지반재해, 연안재해, 바람재해, 기타재해
	③주변지역에 대한 재해영향검토	•주변지역의 장래 토지이용계획 검토 •대상지역 재해영향검토
	④입지의 적정성검토	•재해측면에서의 입지 적정성검토
7.검토항목작성 및 결론	①검토항목 작성	•공통사항 검토 •입지유형별 검토 •협의대상 유형별 검토
	②결론	•결론

2. 행정계획(일반사업계획)

구 분	업무내용	내 용
1.작업계획수립	①작업계획수립	•분야별 작업계획수립 및 협조체계 구축 •자료수집 및 조사일정 수립 •인력투입 및 예정공정표 작성 •기타 과업수행에 필요한 제반사항 검토
2.협의대상의 개요 및 검토항목	①계획수립의 배경과 목적	•계획수립의 배경 •계획의 필요성과 목적
	②사전재해영향성검토 협의 실시 근거	•대상사업의 종류 및 범위 •관련법, 행정계획의 범위, 협의시기
	③계획의 내용	•계획의 명칭, 위치, 면적, 승인기관, 사업시행자, 예산 •계획대상지 위치도 •계획지구의 토지이용계획(도) •계획지구 현장사진
	④계획의 추진경위	•인·허가 절차 및 향후 추진계획
	⑤계획의 협의대상 및 검토항목	•협의대상 및 개요, 협의절차 •공통사항, 입지유형별, 협의대상 유형별 검토항목
3.사전재해영향성검토 대상지역의 설정	①검토대상지역설정을 위한 기초조사	•현지조사, 문헌조사 •관련계획조사
	②검토대상지역 설정	•검토대상지역 설정

구 분	업무내용	내 용
4.기초현황조사	①유역 및 하천현황	•유역 일반현황조사 •대상유역의 경사, 면적, 유로연장, 형상계수조사 •대상유역 내·외의 하천현황, 하천등급, 하천특성, 유로방향조사 •하천의 계획홍수위, 제방고, 개수현황 및 정비상태조사 •대상유역의 토지이용현황 및 계획(도) •대상유역의 유수흐름 및 배수계통도
	②기상, 수문 및 해상특성조사	•관측소(기상, 수문, 해상) 현황조사 •관측자료수집 및 정리
	③지형 및 지질조사	•경사 및 표고 현황조사 •토양 및 지표지질도 조사
	④자연재해저감시설 현황	•자연재해저감시설물 조사 •시설물의 노후화 상태, 기능(작동) 상태 등의 운영 및 관리 평가
	⑤재해지구 관리현황	•재해위험지역조사 •재해위험지구지정 현황도 작성
	⑥재해발생 현황조사	•문헌조사(연도별, 기간별 피해현황조사) •탐문조사
	⑦관련계획조사	•상위계획 및 관련계획조사 •주변지역 개발계획조사
5.재해영향예측 및 평가	①검토의 범위 및 방향 설정	•재해유형별 검토범위 설정 •재해예측 및 분석방향 설정
	②예정용지에 대한 재해예측 및 평가	•정성적 검토 •하천재해, 호우재해, 사면재해, 지반재해, 연안재해, 바람재해, 기타재해
	③공학적 검토를 통한 정량적 분석(필요시)	•정량적 검토 •호우재해(내수침수재해, 홍수유출재해, 토사유출재해)
6.예상재해 저감대책	①기본방향	•사업시행으로 인한 문제점 •재해저감방향
	②예상재해유형별 저감대책	•사업시행전 사전조치 •개발중, 후 재해저감대책수립 •하천재해, 호우재해, 사면재해, 지반재해, 연안재해, 바람재해, 기타재해
	③주변지역에 대한 재해영향검토	•주변지역의 장래토지이용계획검토 •대상지역 재해영향검토
	④입지의 적정성검토	•재해측면에서의 입지 적정성검토
7.검토항목작성 및 결론	①검토항목 작성	•공통사항 검토 •입지유형별 검토 •협의대상 유형별 검토
	②결론	•결론

3. 개발사업

구 분	업무내용	내 용
1.작업계획수립	①작업계획수립	•분야별 작업계획수립 및 협조체계 구축 •자료수집 및 조사일정 수립 •인력투입 및 예정공정표 작성 •기타 과업수행에 필요한 제반사항 검토
2.협의대상의 개요 및 검토항목	①사업의 배경과 목적	•사업의 배경 •사업의 필요성과 목적
	②사전재해영향성 검토 협의 실시 근거	•대상사업의 종류 및 범위 •관련법, 개발사업의 범위, 협의시기
	③사업의 내용	•사업의 명칭, 위치, 면적, 승인기관, 사업시행자, 예산 •사업지구 위치도 •사업지구의 토지이용계획(도) •사업지구 현장사진
	④사업의 추진경위	•인·허가 절차 및 향후 추진계획
	⑤사업의 협의대상 및 검토항목	•협의대상 및 개요, 협의절차 •공통사항, 입지유형별, 협의대상 유형별 검토항목
3.사전재해영향성검토 대상지역의 설정	①검토대상지역설정을 위한 기초조사	•현지조사, 문헌조사 •관련계획조사
	②검토대상지역 설정	•검토대상지역 설정
4.기초현황조사	①유역 및 하천현황	•유역 일반현황조사 •대상유역의 경사, 면적, 유로연장, 형상계수조사 •대상유역 내·외의 하천현황, 하천등급, 하천특성, 유로방향조사 •하천의 계획홍수위, 제방고, 개수현황 및 정비상태조사 •대상유역의 토지이용현황 및 계획(도) •대상유역의 유수흐름 및 배수계통도
	②기상, 수문 및 해상특성조사	•관측소(기상, 수문, 해상) 현황조사 •관측자료수집 및 정리
	③지형 및 토질조사	•경사 및 표고 현황조사 •토양 및 지표지질도 조사 •토질현황(현장시험, 주상도, 지하수위관측) •절토, 성토사면 및 자연사면의 분포
	④자연재해저감시설 현황	•자연재해저감시설물 조사 •시설물의 노후화 상태, 기능(작동) 상태 등의 운영 및 관리 평가
	⑤재해지구 관리현황	•재해위험지역조사 •재해위험지구지정 현황도 작성

구 분	업무내용	내 용
4.기초현황조사	⑥재해발생 현황조사	•문헌조사(연도별, 기간별 피해현황조사) •탐문조사
	⑦관련계획조사	•상위계획 및 관련계획조사 •주변지역 개발계획조사
5.재해영향예측 및 평가	①검토의 범위 및 방향 설정	•재해유형별 검토범위 설정 •재해예측 및 분석방향 설정
	②예정용지에 대한 재해예측 및 평가	•정성적 검토 •하천재해, 호우재해, 사면재해, 지반재해, 연약재해, 바람재해, 기타재해
	③공학적 검토를 통한 정량적 분석	•정량적 검토 •하천재해위험도 평가 •호우재해 위험도 평가(내수침수재해, 홍수유출재해, 토사유출재해) •사면안정성검토 •지반재해 안정성검토 •연안재해위험도 평가 •바람재해위험도 평가 •기타 재해위험도 평가
6.예상재해 저감대책	①기본방향	•사업시행으로 인한 문제점 •재해저감방향
	②예상재해유형별 저감대책	•사업시행전 사전조치 •개발중, 후 재해저감대책수립 •하천재해, 호우재해, 사면재해, 지반재해, 연안재해, 바람재해, 기타재해
	③주변지역에 대한 재해영향검토	•주변지역 개발계획검토 •대상지역 재해영향검토
	④예정용지의 재해영향적 적정성 검토	•재해저감시설의 필요성 검토 •재해대책 총괄표 •재해저감대책도
7.유지관리계획	①개발중 유지관리계획	•개발중 저감시설 유지관리계획 •관리책임자 지정 •개발중 유지관리대장 작성
	②개발후 유지관리계획	•개발후 저감시설 유지관리계획 •관리책임자 지정 •개발후 유지관리대장 작성
8.검토항목 작성 및 결론	①검토항목 작성	•공통사항 검토 •입지유형별 검토 •협의대상 유형별 검토
	②결론	•결론

7-7 표준성과품

○ 사전재해영향성검토 협의시에는 검토서, 현장사진첩 등의 성과품이 작성되어야 하며 그 외에 측량, 토질 및 지질조사 등의 업무를 추가적으로 수행할 경우에는 조사 및 분석내용, 결과 등의 작업성과를 일목요연하게 정리하여 제출하여야 한다.

성과구분	표준성과도서			비 고
	구 분	규 격	제 출 부 수	
보고서	검토보고서 조치 계획서	A4	10부 10부	
기 타	측량성과품 토질 및 지질조사성과 현장조사사진첩 CD	- - - -	1 식 1 식 1 식 1 식	야장포함

주 : ①제출부수 및 성과품 종류가 증가할 경우에는 증가배수에 해당하는 작업품과 비용을 가산한다.
②계획보고서 및 기타 관련자료의 규격 및 제출부수는 발주자와의 협의에 의하여 비용을 산정한다.

제8절 교육환경평가

8-1 정 의

○ 교육환경평가는 「학교보건법」제6조의2에 따라 학교의 학습환경을 보다 근본적으로 확보·보전하기 위하여 학교용지를 선정할 때 필요로 하는 제반 검토 분석 및 이에 필요한 도서작성업무를 말한다.

8-2 자료제공의 전제

○ 교육환경평가 관한 업무에 필요한 모든 관련자료는 원칙적으로 발주자가 제공하는 것으로 하되, 발주자가 보유하지 않는 자료는 엔지니어링사업자가 수집한다.

○ 발주자가 제공하지 못하는 자료의 조사에 있어서는 그 규모·내용에 의거하여 별도의 엔지니어링사업대가를 산정하여 엔지니어링사업자가 수행하며, 관련자료의 기밀성과 광범위한 자료가 필요한 경우 조사·분석에 필요한 상당기간과 자료수집비용이 전제되어야 한다.

8-3 업무범위와 추진과정

8-3-1 업무범위

○ 교육환경평가 업무의 범위는 교육환경평가에 대한 검증 등을 위해서 갖추어야 할 제반도서 가운데 엔지니어링사업자의 기술적 능력이 요구되는 부분의 작성으로 학교용지선정자는 평가서를 작성할 때 기타 기술내용을 추가할 수 있다.

8-3-2 추진과정

○ 타부처(관계기관)와 협의나 전문가 자문 등에 소요되는 기간은 과업수행기간에서 제외하여 그 소요기간만큼 과업수행기간을 연장하여야 한다.

교육환경평가에 관한 업무추진절차

학교설립계획 또는 개발계획 검토

↓

교육환경평가서 작성

↓

교육환경평가서 검토

↓

교육환경평가서 심의

↓

교육환경평가 결과 수정

<국토교통부장관>

8-4 품 산정의 원단위 산정과 기준

8-4-1 표준품 산정내역

○ 표준품 산정의 기준이 되는 비목은 제1장 총칙에서 제시한 비목을 중심으로 하였으며, 교육환경평가에 관한 업무에 필요한 사항만을 대상으로 한다.

○ 표준품 산정의 기본이 되는 직접인건비 품의 작업항목별 보할은 업무의 난이도를 감안하여 설정토록 한다.

종 별		내 용	세부항목	단 위	비 고
직접비	직접인건비	1.요약문	①요약서 작성	인·일	
		2.사업개요	①사업개요 작성	인·일	
		3.평가항목별 조사	①학교위치 ②학교크기 및 외형 ③지형 및 토양환경 ④대기환경 ⑤주변환경 ⑥공공시설	인·일 〃 〃 〃 〃 〃	
		4.종합평가	①종합평가 작성	인·일	
		5.성과품 작성	①성과품 작성	인·일	
	직접경비	여비, 인쇄비, 조감도, 회의준비비, 현장운영비 등		식	제1장 총칙참조
간접비	제경비	(직접인건비) × 120%		〃	〃
	기술료	(직접인건비+제경비) × 30%		〃	〃

8-4-2 산정기준

1. 계획·기준면적 선정

○ 교육환경평가에 관한 업무에 있어서의 원단위 설정을 위한 기준면적은 30만㎡, 기준개소수는 4개교로 선정한다.

○ 계획면적은 과업면적을 원칙으로 한다.

2. 표준품의 산정방법

○ 표준품의 적용에 있어 위 기준면적과 계획면적의 차이 및 기준소수와 계획개소수에 따른 산정은 아래의 수정식에 따라 기준면적의 소요작업량을 수정하여 산정한다.

○ 소요작업량 = 기준면적소요작업량 × 면적보정계수(α) × 학교수보정계수(β)

3. 평가서 내용의 수정과 과업중지 등에 따른 산정방법

○ 계획안이 작성되고 주민의견, 의회보고 등 행정절차과정을 거쳐 계획안이 확정된 후 발주자의 사정에 의하여 평가서 내용이 일부변경 · 재작업이 수행되는 경우에는 그 변경·재작업의 정도에 따라 엔지니어링사업대가의 50～100% 수준에서 비용을 추가 지급하여야 한다.

○ 과업수행 중 발주자의 사정에 따른 과업 중단으로 인해 정부 회계연도가 경과되어 현저한 비용의 차이가 발생하였을 경우에는 엔지니어링사업대가를 당해 신년도의 노임단가를 기준으로 재산정하여야 한다.

8-4-3 단위별 변화수정과 보정

1. 면적의 대소에 대한 작업량 보정계수 산정

○ 교육환경평가에 관한 업무 계획면적이 기준면적을 초과하거나 이에 못 미치는 경우의 직접인력 소요작업량의 산정을 위한 각 작업내용별 면적보정계수(α)는 다음과 같이 산정한다.

$$\alpha = (\frac{\text{계획면적}}{\text{기준면적}})^{0.2} = (\frac{A}{30})^{0.2}$$

α = 면적보정계수
A = 계획면적(만㎡)

계획단위 면적별 보정계수

면 적 (만㎡)	면적보정계수(α)	면 적 (만㎡)	면적보정계수(α)
10	0.803	60	1.149
20	0.922	80	1.217
30	1.000	90	1.246
40	1.059	100	1.272
50	1.108	200	1.461

주 : 계획면적이 10만㎡미만인 경우에는 계획면적 10만㎡를 기준으로 하여 산정한다.

2. 학교수 대소에 대한 작업량 보정계수 산정

○ 교육환경평가에 관한 업무 기준개수를 초과하거나 이에 못 미치는 경우의 직접인력 소요작업량의 산정을 위한 각 작업내용별 학교수보정계수(β)는 다음과 같이 산정한다.

$$\beta = (\frac{\text{계획학교수}}{\text{기준학교수}})^{0.25} = (\frac{B}{4})^{0.25}$$

β = 학교수보정계수
B = 계획학교수(개교)

3. 직접인건비 소요 작업량 산정

○ 계획면적의 대소에 따른 직접인력 소요작업량의 산정방법은 아래와 같이 기준면적의 직능별 직접인력 소요작업량에 계획단위 보정계수(α β)를 곱하여 산출한다.

구 분	기준면적(만㎡) 기준개소(개교)	총작업량 (인·일)					
		기술사	특 급	고 급	중 급	초 급	보조원
교육환경 평가	30 4	-	8.2α β	12.6α β	24.3α β	28.4α β	-

8-5 표준단위 업무분류와 원단위

기술업무의 직능별 직접인력에 의한 소요작업량(30만㎡ 기준)

(단위 : 인·일/표준단위)

내 용	세부항목	표준 단위	소요인력(인·일)						비 고
			기술사	특급	고급	중급	초급	보조원	
1.요약문	①요약문	30만㎡	-	0.1	0.1	0.2	0.2	-	
2.사업의 개요	①사업의 개요	30만㎡	-	1.0	1.4	1.8	1.6	-	
3.평가항목별 조사	①학교의 위치	30만㎡	-	0.9	0.8	1.4	1.9	-	
	②학교크기 및 외형	30만㎡							
	③지형 및 토양환경	30만㎡	-	1.6	3.3	5.7	5.0	-	
	④대기환경	30만㎡	-	3.9	5.6	12.9	16.2	-	
	⑤주변환경	30만㎡	-	0.2	0.6	1.4	2.2	-	
	⑥공공시설	30만㎡							
4.종합평가	①종합평가	30만㎡	-	0.4	0.4	0.5	0.3	-	
5.성과품 작성	①성과품 작성	30만㎡	-	0.1	0.4	0.4	1.0	-	
총 계			-	8.2	12.6	24.3	28.4	-	
6.기술협의	①공청회/주민설명회	1식	-	2.0	2.0	4.0	4.0	-	주1
	②주민간담회/시민계획단	1식	-	2.0	2.0	4.0	4.0	-	
	③위원회심의 지원	1식	-	2.0	2.0	4.0	4.0	-	
	④관계기관 협의	1식	-	2.0	2.0	4.0	4.0	-	
	소 계		-	8.0	8.0	16.0	16.0	-	

주 : ①기술협의는 2회 이내 기준이며, 횟수가 늘어날 경우 증가배수에 해당하는 작업품과 비용을 가산한다. (필요항목 선택적 적용)

8-6 주요업무내용

구 분	업무내용	내 용
1.요약문	①요약서 작성	·개발사업의 내용, 평가항목별 조사내용, 종합평가
2.사업개요	②사업개요 작성	·개발사업의 개요, 교육환경평가 근거 및 기준검토
3.평가항목별 조사	①학교 위치	·학습환경, 통학범위, 학생수용계획, 도로접근성 조사
	②학교크기 및 외형	·학교면적 및 학생수 산정, 학교대지 길이와 폭의 비율 조사
	③지형 및 토양환경	·경사도 및 토지의 안정성, 풍수해, 토지의 과거 이용 현황, 지형형상, 지질상황, 토질오염등 조사
	④대기환경	·대기, 소음, 진동, 학교대지의 장축방향 및 방위축방향, 일조권 침해 건축물 조사
	⑤주변환경	·학교환경위생정화구역 내 금지행위 및 시설현황, 학교주변 유해환경 시설현황 조사
	⑥공공시설	·상수도, 전기, 도시가스 및 하수시설 등의 이용가능 여부 조사
4.종합평가	①종합평가 작성	·학교별 평가 및 종합평가 기술

8-7 표준성과품

성과구분	표준성과도서			비 고
	구 분	규 격	제출부수	
관련도서	1. 교육환경평가 결과보고서	1 식	40부	

주 : ①제출부수 및 성과품 종류가 증가할 경우에는 증가배수에 해당하는 작업품과 비용을 가산한다.
②계획보고서 및 기타 관련자료의 규격 및 제출부수는 발주자와의 협의에 의하여 비용을 산정한다.

제9절 도시계획지속가능성평가

9-1 정 의

○ 도시계획지속가능성평가는 전 국토의 “지속가능한 개발”을 위해 지자체의 건전한 도시정책을 유도하고 국민 삶의 질을 개선하기 위한 생활인프라 수준을 평가하기 위해「국토의 계획 및 이용에 관한 법률」 제3조2의 규정에 의해 계획 입안 후 결정요청 전 실시하는 평가이다.

9-2 자료제공의 전제

○ 당해 계획의 수립에 필요한 모든 관련 자료는 원칙적으로 발주자가 제공하는 것으로 하되, 발주자가 보유하지 않는 자료는 엔지니어링사업자가 수집한다.

○ 발주자가 제공하지 못하는 자료의 조사에 있어서는 그 규모·내용에 의거하여 별도의 엔지니어링사업대가를 산정하여 엔지니어링사업자가 수행하며, 당해 관련 자료의 기밀성과 광범위한 자료가 요구될 경우는 조사·분석에 필요한 상당기간과 자료수집비용이 전제되어야 한다.

9-3 업무범위와 추진과정

9-3-1 업무범위

○ 도시계획지속가능성평가는 도시의 개발에 따른 토지이용의 효율성, 환경친화성, 기반시설 공급의 적정성, 생활공간의 안전성 · 쾌적성 · 편의성 등을 종합적으로 고려하여 평가서를 작성하여 제출하고, 국토교통부가 이를 검증한 후 종합분석 및 평가를 통해 평가위원회 의견을 들어 최종결과를 도출 확정한 후 이를 정리하여 최종보고서를 작성하는 등 일련의 과정을 업무범위로 한다.

9-3-2 추진과정

도시계획지속가능성평가 추진과정

평가 시행 공고 (국토교통부장관)	·평가의 목적 및 의의, 평가지표 및 평가자료, 평가방법, 평가기간 등을 담은 내용과 양식 공고
평가서의 작성 및 제출	·지자체장 : 60일 이내 평가보고서 제출 ·지차체 평가보고서의 공신력을 높이기 위해 지방도시계획위원회 자문 가능
평가서의 접수	·평가자료 목록과의 누락여부 ·지표별 평가자료의 공신력과 증빙자료의 충실여부 ·자료양식과의 부합여부 검토 ·평가자료 부합여부 확인
평가결과 도출 (평가위원회 의견개진)	·검증완료 후 종합분석 및 평가 실시를 통하여 평가위원회 의견을 들어 최종결과 도출 확정
평가 결과보고서 작성 및 통보	·평가결과 부문별·이슈별 정리 및 최종보고서 작성 ·지자체별 평가결과 및 평가과정상 애로사항 및 개선방안 제안 ·최종보고서와 평가결과 통보

9-4 품 산정의 원단위 산정과 기준

9-4-1 표준품 산정내역

○ 표준품 산정의 기준이 되는 비목은 제1장 총칙에서 제시한 비목을 중심으로 하였으며, 이는 도시계획지속가능성평가에 필요한 사항만을 대상으로 한다.

○ 표준품 산정의 기본이 되는 직접인건비 품의 작업항목별 보할은 기존의 경험적 내용 및 항목별 업무의 난이도를 감안하여 설정토록 한다

종 별		내 용	단 위	비 고
직접비	직접인건비	1.현황조사 분석 2.평가서 작성 3.성과품작성 4.기술협의	인·일 〃 〃 〃	
	직접경비	여비, 인쇄비, 조감도, 회의준비비, 현장운영비 등	식	제1장 총칙참조
간접비	제경비	(직접인건비) × 110%	〃	〃
	기술료	(직접인건비+제경비) × 30%	〃	〃

9-4-2 산정 기준

1. 계획·기준인구의 설정

○ 기준인구는 전국 시·군의 인구분포를 분석하여 인구 50만인으로 하였으며, 직능별 직접인력 소요작업량은 기 작성된 시·군 도시·군기본계획 등의 투입기술자 비율을 감안하여 설정한다.

2. 표준품의 산정방법

○ 표준품의 적용에 있어 기준인구와 계획인구의 차이에 따른 품 산정은 아래의 수정식에 따라 기준인구의 소요작업량을 수정하여 산정한다.

○ 소요작업량 = 기준인구 소요작업량 × 인구보정계수(α)

3. 평가서의 수정과 과업중지에 따른 품 산정방법

○ 도시계획지속가능성평가 성과물이 작성되고 관련계획이 행정절차과정을 거치는 과정에서 발주자의 사정에 의하여 평가서 내용이 일부변경 · 재작업이 수행되는 경우에는 그 변경·재작업의 정도에 따라 엔지니어링사업대가의 50～100% 수준에서 비용을 추가 지급하여야 한다.

○ 과업수행 중 발주자의 사정에 따른 과업 중단으로 인해 정부 회계연도가 경과되어 현저한 비용의 차이가 발생하였을 경우에는 엔지니어링사업대가를 당해 신년도의 노임단가를 기준으로 재산정하여야 한다.

9-4-3 단위별 변화수정과 보정

1. 인구의 대소에 대한 작업량 보정계수 산정

○ 도시계획지속가능성평가 대상 면적이 기준면적을 초과하거나 이에 못 미치는 경우의 직접인력 소요작업량의 산정을 위한 각 작업내용별 보정계수(α)는 다음과 같이 산정한다.

$$\alpha = (\frac{\text{계획인구}}{\text{기준인구}})^{0.5} = (\frac{A}{50})^{0.5}$$

α = 보정계수
A = 계획인구(만인)

계획단위 면적에 대한 작업량 보정계수

계획인구(만인)	보정계수(α)	계획인구(만인)	보정계수(α)
10	0.447	90	1.341
20	0.632	100	1.414
30	0.774	200	2.000
50	1.000	400	2.449
70	1.183	500	3.162

주 : 계획인구가 10만인 미만인 경우에는 계획인구 10만인을 기준으로 하여 산정한다.

2. 직접인건비 소요 작업량 산정

○ 계획인구의 대소에 따른 직접인력 소요작업량의 산정방법은 아래와 같이 기준인구의 직능별 직접인력 소요작업량에 계획단위면적의 보정계수(α)를 곱하여 산출한 값에 기술협의 및 직정경비 값을 더하여 산출한다.

구 분	기준인구 (만인)	총작업량 (인·일)					
		기술사	특 급	고 급	중 급	초 급	보조원
도시계획지속 가능성평가	50	4.5α	11.5α	31.2α	55.2α	89.8α	105.2α

9-5 표준단위 업무분류와 원단위

기술업무의 직능별 직접인력 소요작업량(인구 50만인 기준)

(단위 : 인·일/표준단위)

구분	업무내용	표준 단위	소요인력						비고
			기술사	특급	고급	중급	초급	보조원	
1.현황조사 분석	①현황조사 및 자료수집	50만인	0.7	1.8	5.2	16.6	21.0	27.4	
2.평가서 작성	①평가지표 및 평가기준	50만인	1.5	3.0	9.0	15.0	21.0	27.0	
	②평가지표 자료구축	50만인	1.3	4.4	11.4	14.7	33.8	32.8	
	③부문별 등급 및 종합화	50만인	0.5	1.0	3.0	5.0	7.0	9.0	
3.성과품 작성	①보고서 작성 및 편집	50만인	0.5	1.3	2.6	3.9	7.0	9.0	
총 계			4.5	11.5	31.2	55.2	89.8	105.2	
4.기술협의	①공청회/주민설명회	1식	2.0	2.0	2.0	4.0	4.0	4.0	주1
	②주민간담회/시민계획단	1식	2.0	2.0	2.0	4.0	4.0	4.0	
	③위원회심의 지원	1식	2.0	2.0	2.0	4.0	4.0	4.0	
	④관계기관 협의	1식	2.0	2.0	2.0	4.0	4.0	4.0	
	소 계		8.0	8.0	8.0	16.0	16.0	16.0	

주 : ①기술협의는 2회 이내 기준이며, 횟수가 늘어날 경우 증가배수에 해당하는 작업품과 비용을 가산한다. (필요항목 선택적 적용)

9-6 주요업무내용

구 분	내 용
1.현황조사 분석	·토지이용부문 : 개발행위의 시가화구역 집중정도, 도시내 토지의 절약적 이용정도, 토지수요량 적정정도, 비시가화 지역내 토지의 계획적 공급정도 ·산업·경제부문 : 경제활동 활력정도, 기업설립 정도, 재정자립정도 ·환경보전부문 : 상하수도 보급정도, 산림지역 보전정도, 온실가스 배출정도, 쓰레기 재활용정도 ·문화·경관부문 : 문화체육시설 확충정도, 공원조성정도, 주민만남의장 조성정도, 가로경관 개선정도 ·교 통 부 문 : 대중교통 이용편리성 정도, 교통약자 안전성 제고정도, 교통사고 안전성 정도, 적정 주차공간 확보정도 ·주 택 부 문 : 주택의 노후정도, 노후주택의 개선정도, 최조주거기준 확보정도, 저소득가구의 주거안정정도 ·사회·복지부문 : 보육원·유치원,초등학교 공급정도, 노인전문시설 공급정도, 의료서비스 수준 ·방 재 · 안 전 : 자연재해 피해정도, 재해예방시설 확충정도, 범죄로부터의 안정성정도
2.평가서 작성	·평가지표 및 평가기준 ·평가지표 자료구축 ·부문별 등급 및 종합화

9-7 표준성과품

성과구분	표준성과도서			비 고
	구 분	규 격	제출부수	
평가서	·도시계획지속가능성평가서		1부	
결과보고서	·평가 최종결과보고서		1부	
CD	·자료CD		1식	

주 : ①제출부수 및 성과품 종류가 증가할 경우에는 증가배수에 해당하는 작업품과 비용을 가산한다.
②계획보고서 및 기타 관련자료의 규격 및 제출부수는 발주자와의 협의에 의하여 비용을 산정한다.

제10절 환경평가검증에 관한 업무(도시·군기본계획수립을 위한)

10-1 정 의

○ 환경평가검증에 관한 업무란 환경평가에 사용된 도면, 자료의 입력과정의 오류와 현재시점에서 활용 가능한 자료를 이용한 보정을 통하여 친환경적 광역도시계획 및 도시·군기본계획 그리고 도시재정비계획 등 도시 및 지역관련계획의 수립 및 변경에 필요한 기초자료를 제공하는 도서작성업무를 말한다.

10-2 자료제공의 전제

○ 환경평가검증에 관한 업무에 필요한 모든 관련자료는 원칙적으로 발주자가 제공하는 것으로 하되, 발주자가 보유하지 않는 자료는 엔지니어링사업자가 수집한다.

○ 발주자가 제공하지 못하는 자료의 조사에 있어서는 그 규모·내용에 의거하여 별도의 엔지니어링사업대가를 산정하여 엔지니어링사업자가 수행하며, 관련자료의 기밀성과 광범위한 자료가 필요한 경우 조사·분석에 필요한 상당기간과 자료수집비용이 전제되어야 한다.

10-3 업무범위와 추진과정

10-3-1 업무범위

○ 환경평가검증업무의 범위는 환경평가에 대한 검증 등을 위해서 갖추어야 할 제반도서 가운데 엔지니어링사업자의 기술적 능력이 요구되는 부분의 작성으로 한다. 단 환경현황에 대한 측정이나 현지확인 또는 시료분석 등은 제외한다.

10-3-2 추진과정

○ 타부처(관계기관)와 협의나 전문가 자문 등에 소요되는 기간은 과업수행기간에서 제외하여 그 소요기간만큼 과업수행기간을 연장하여야 한다.

환경평가 검증에 관한 업무추진절차

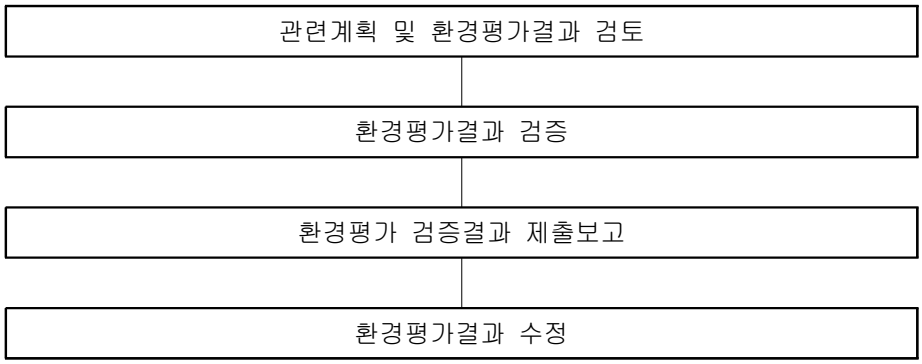

10-4 품 산정의 원단위 산정과 기준

10-4-1 표준품 산정내역

○ 표준품 산정의 기준이 되는 비목은 제1장 총칙에서 제시한 비목을 중심으로 하였으며, 환경평가에 관한 업무에 필요한 사항만을 대상으로 한다.

○ 표준품 산정의 기본이 되는 직접인건비 품의 작업항목별 보할은 업무의 난이도를 감안하여 설정토록 한다.

종 별		내 용	세부항목	단 위	비 고
직접비	직접인건비	1. 개발계획 검토	①관련법규 검토 ②관련계획 검토 ③주변지역과의 상관성검토 ④환경평가결과 검토	인·일 〃 〃 〃	
		2.환경평가 결과 검증	①표고검증 ②경사도검증 ③농업적성도 검증 ④식물상 검증 ⑤임업적성도 검증 ⑥수질 검증	〃 〃 〃 〃 〃 〃	
		3.성과품 작성	①환경평가검증 결과보고서 ②검증결과 조서 ③검증결과 도면	〃	
		4.기술협의	①공청회 / 주민설명회 ②주민간담회 / 시민계획단 ③위원회 심의 지원 ④관계기관 협의	〃 〃 〃 〃	
	직접경비	여비, 인쇄비, 조감도, 회의준비비, 현장운영비 등		식	제1장 총칙참조
간접비	제경비	(직접인건비)×110%		〃	〃
	기술료	(직접인건비+제경비) ×20%		〃	〃

10-4-2 산정기준

1. 계획·기준면적 선정

○ 환경평가검증에 관한 업무에 있어서의 원단위 설정을 위한 기준면적은 100만㎡로 선정한다.

○ 계획면적은 과업면적을 원칙으로 한다.

2. 표준품의 산정방법

○ 표준품의 적용에 있어 위 기준면적과 계획면적의 차이에 따른 산정은 아래의 수정식에 따라 기준면적의 소요작업량을 수정하여 산정한다.

○ 소요작업량 = 기준면적소요작업량 × 면적보정계수(α)

3. 검증서의 수정과 과업중지 등에 따른 산정방법

○ 검증서가 작성되고 주민의견, 의회보고 등 행정절차과정을 거쳐 계획안이 확정된 후 발주자의 사정에 의하여 계획안이 일부변경·재작업이 수행되는 경우에는 그 변경·재작업의 정도에 따라 엔지니어링사업대가의 50～100% 수준에서 비용을 추가 지급하여야 한다.

○ 과업수행 중 발주자의 사정에 따른 과업 중단으로 인해 정부 회계연도가 경과되어 현저한 비용의 차이가 발생하였을 경우에는 엔지니어링사업대가를 당해 신년도의 노임단가를 기준으로 재산정하여야 한다.

10-4-3 단위별 변화수정과 보정

1. 면적의 대소에 대한 작업량 보정계수 산정

○ 환경평가검증에 관한 업무 계획면적이 기준면적을 초과하거나, 이에 못 미치는 경우의 직접인력 소요작업량의 산정을 위한 각 작업내용별 면적보정계수(α)는 다음과 같이 산정한다.

$$\alpha = \left(\frac{\text{계획면적}}{\text{기준면적}}\right)^{0.5} = \left(\frac{A}{100}\right)^{0.5}$$

α = 면적보정계수
A = 계획면적(만㎡)

계획단위 면적별 보정계수

면적 (만㎡)	면적보정계수 (α)	면적 (만㎡)	면적보정계수 (α)
10	0.316	90	0.949
30	0.548	100	1.000
50	0.707	150	1.225
70	0.837	200	1.414
80	0.894	300	1.732

주 : 계획면적이 10만㎡미만인 경우에는 계획면적 10만㎡를 기준으로 하여 산정한다.

2. 직접인건비 소요 작업량 산정

○ 계획면적의 대소에 따른 직접인력 소요작업량의 산정방법은 아래와 같이 기준면적의 직능별 직접인력 소요작업량에 계획단위 보정계수(α)를 곱하여 산출한다.

구 분	기준면적 (만㎡)	총 작 업 량 (인·일)					
		기술사	특 급	고 급	중 급	초 급	보조원
환경평가검증	100	3.0α	8.2α	23.0α	33.6α	62.8α	73.3α

10-5 표준단위 업무분류와 원단위

기술업무의 직능별 직접인력에 의한 소요작업량(100만㎡ 기준)

(단위 : 인·일/표준단위)

업무내용		표준단위	소요인력						비고
			기술사	특 급	고 급	중 급	초 급	보조원	
1.개발계획 검토	①관련법규 검토	100만㎡	0.1	0.2	0.4	0.6	1.1	1.3	
	②관련계획 검토	100만㎡	0.1	0.2	0.4	0.6	1.1	1.3	
	③주변지역과의 상관성 검토	100만㎡	0.1	0.3	0.6	0.9	1.6	1.9	
	④환경평가결과 검토	100만㎡	0.2	0.6	1.2	1.8	3.2	3.8	
	소 계		0.5	1.3	2.6	3.9	7.0	8.3	
2.환경평가결과검증	①표고 검증	100만㎡	0.3	0.9	1.8	2.6	4.9	5.6	
	②경사도 검증	100만㎡	0.3	0.9	1.8	2.6	4.9	5.6	
	③농업적성도 검증	100만㎡	0.4	1.0	5.3	7.7	14.6	16.8	
	④식물상 검증	100만㎡	0.3	0.9	1.8	2.6	4.9	5.6	
	⑤임업적성도 검증	100만㎡	0.3	0.9	1.8	2.6	4.9	5.6	
	⑥수질 검증	100만㎡	0.4	1.0	5.3	7.7	14.6	16.8	
	소 계		2.0	5.6	17.8	25.8	48.8	56.0	
3.성과품작성	①환경평가검증 결과보고서	100만㎡	0.3	0.7	1.6	2.5	3.0	5.0	
	②검증결과 조서	100만㎡	0.1	0.3	0.5	0.7	2.0	2.0	
	③검증결과 도면	100만㎡	0.1	0.3	0.5	0.7	2.0	2.0	
	소 계		0.5	1.3	2.6	3.9	7.0	9.0	
총 계			3.0	8.2	23.0	33.6	62.8	73.3	
4.기술협의	①공청회/주민설명회	1식	2.0	2.0	2.0	4.0	4.0	4.0	
	②주민간담회/시민계획단	1식	2.0	2.0	2.0	4.0	4.0	4.0	
	③위원회심의 지원	1식	2.0	2.0	2.0	4.0	4.0	4.0	주1
	④관계기관 협의	1식	2.0	2.0	2.0	4.0	4.0	4.0	
	소 계		8.0	8.0	8.0	16.0	16.0	16.0	

주 : ①기술협의는 2회 이내 기준이며, 횟수가 늘어날 경우 증가배수에 해당하는 작업품과 비용을 가산한다. (필요항목 선택적 적용)

②환경현황에 대한 측정이나 현지확인 또는 시료분석 등은 발주자가 직접경비로 별도로 부담하되 그 범위는 발주자와 과업수행자간의 협의로 결정한다.

10-6 주요업무내용

구 분	업무내용	내 용
1. 개발계획 검토	①관련법규 검토	·환경평가 및 검증에 필요한 관계법 검토
	②관련계획 검토	·환경평가 및 검증과 관련된 상위 및 관련계획검토
	③주변지역과의 상관성 검토	·당해 지역과 주변지역 관련사항 검토
	④환경평가결과 검토	·환경평가 결과와 관련사항 검토
2. 환경평가결과 검증	①표고 검증	·지형도상의 등고선과 환경평가 표고등급기준의 비교검증
	②경사도 검증	·지형도상의 경사도와 환경평가 경사도등급기준의 비교검증
	③농업적성도 검증	·농업진흥지역, 경지정리지구, 용수개발구역, 농지생산성 급지, 농업적성도 등에 대한 확인검증
	④식물상 검증	·임상도상의 임종분포와 영급분포 등에 대한 확인검증
	⑤임업적성도 검증	·간이 산림토양도상의 임지 생산능력 급지 확인검증
	⑥수질 검증	·취수원, 하천. 호수별 수질환경과 등급, 폐수배출허용기준 등에 대한 확인검증

10-7 표준성과품

성과구분	표준성과도서			비 고
	구 분	규 격	제출부수	
관련도서	1.환경평가검증 결과보고서 2.검증결과 조서 3.검증결과 도면	1 식 〃 1/5,000-1/25,000	3부 3부 3부	

주 : ①제출부수 및 성과품 종류가 증가할 경우에는 증가배수에 해당하는 작업품과 비용을 가산한다.
②계획보고서 및 기타 관련자료의 규격 및 제출부수는 발주자와의 협의에 의하여 비용을 산정한다.

제9장 공원·관광지·유원지·체육시설 등의 계획

제1절 공원녹지 기본계획

제2절 도시녹화계획

제3절 공원계획

제4절 관광지·유원지·휴양지·체육시설지 계획

제5절 문화재 사적지 계획

제1절 공원녹지 기본계획

1-1 정 의

○ 공원녹지 기본계획은 「도시공원 및 녹지 등에 관한 법률」에 의한 도시공원, 녹지, 유원지, 공공공지 및 저수지, 도시자연공원구역과 나무, 잔디, 꽃, 지피식물 등의 식생이 자라는 공간을 포함하며 도시지역에 대한 공원녹지의 확충·관리·이용방향을 종합적으로 제시함으로서 쾌적한 도시환경을 조성하여 건전하고 문화적인 도시생활의 확보와 공공복리를 증진시키기 위한 전반적인 계획 그리고 타당성 검토를 말한다.

1-2 자료제공의 전제

○ 공원녹지 기본계획에 필요한 모든 관련자료(도시의 지형·자원·생태 등 자연여건자료, 경관·방재조사자료, 상위계획, 공원녹지 관련 등)는 원칙적으로 발주자가 제공하는 것으로 한다.

○ 발주자가 제공하지 못하는 자료의 조사에 있어서는 그 규모·내용에 의거하여 별도의 엔지니어링사업대가를 산정하여 엔지니어링사업자가 수행하며, 관련 자료의 기밀성과 광범위한 자료가 요구되는 경우 조사·분석에 필요한 상당기간과 자료수집비용이 전제되어야 한다.

1-3 업무범위와 추진과정

1-3-1 업무범위

○ 공원녹지 기본계획은 「도시공원 및 녹지 등에 관한 법률」 제 2장 제6조 ①항에 규정한 내용을 주요업무범위로 한다.

1-3-2 추진과정

○ 타 부처(관계기관)와의 협의나 전문가 자문 등에 소요되는 기간은 과업수행기간에서 제외하여 그 소요기간만큼 과업수행기간을 연장하여야 한다.

공원녹지 기본계획 업무추진과정

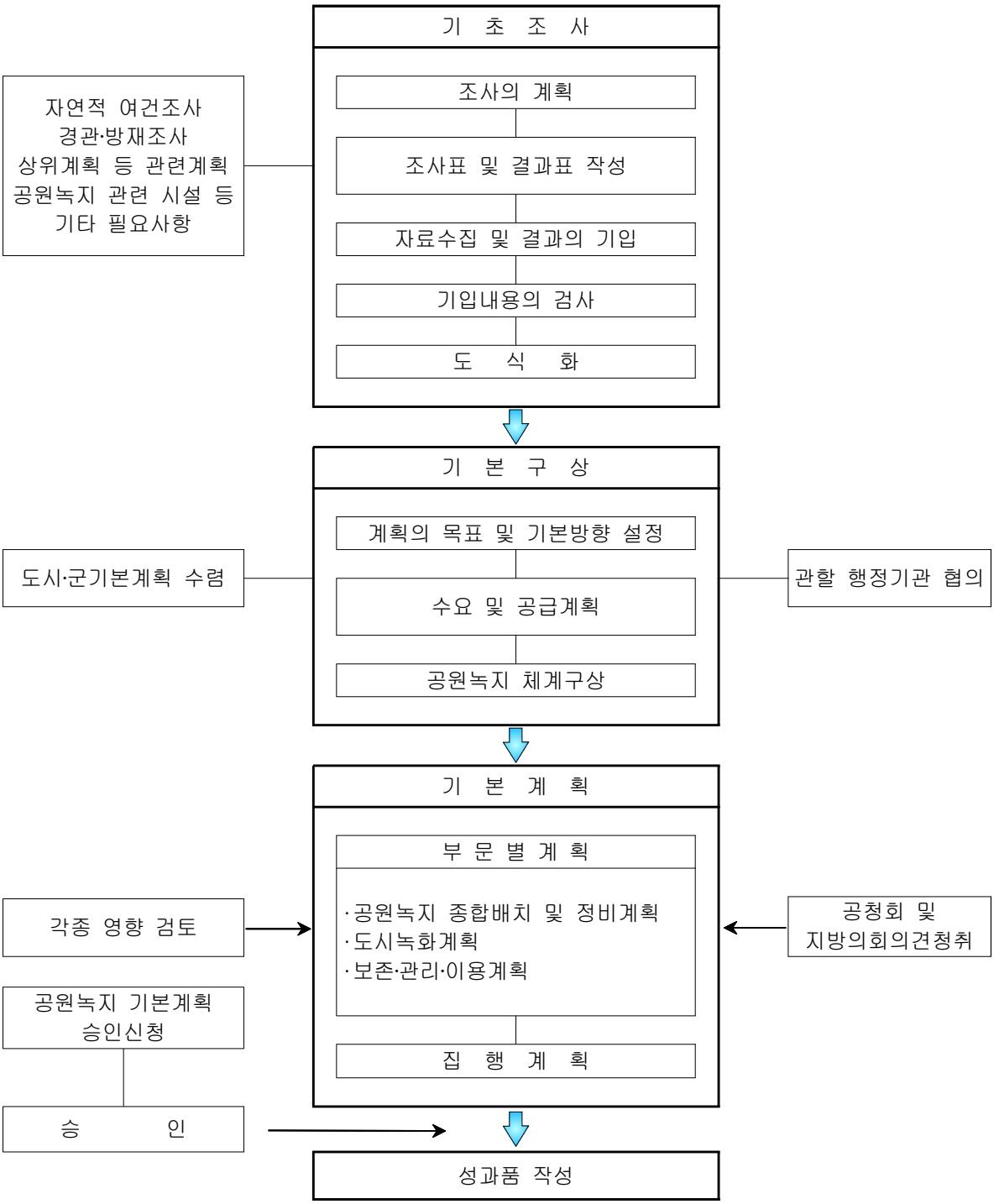

1-4 품 산정의 원단위 산정과 기준

1-4-1 표준품 산정내역

○ 표준품 산정의 기준이 되는 비목은 제1장 총칙에서 제시한 비목을 중심으로 하였으며, 이는 공원계획에 필요한 사항만을 대상으로 한다.

○ 표준품 산정의 기본이 되는 직접인건비 품의 작업항목별 보할은 업무의 난이도를 감안하여 설정토록 한다.

1. 공원녹지 기본계획의 수립을 위한 기초조사

○ 대상 행정구역 지역의 자연·인문여건조사, 경관·방재조사, 기타 공원녹지 관련시설 현황 등 공원녹지 기본계획 수립을 위한 기초 자료는 별도의 품을 적용한다.

2. 기본계획의 표준산정내역

종 별		내 용	세부항목	단 위	비 고
직접비	직접인건비	1.기초조사	①기초자료조사 및 수집 ②공원녹지 여건분석 ③종합분석 및 계획과제 도출	인·일 〃 〃	
		2.기본구상	①계획의 목표 및 기본방향 ②수요 및 공급계획 ③공원녹지 체계구상	〃 〃 〃	
		3.기본계획	①공원녹지 종합배치계획 ②공원녹지조성 및 정비계획 ③도시녹화계획 ④보전관리, 이용계획 ⑤각종 영향 검토	〃 〃 〃 〃 〃	
		4.집행계획	①예산 및 재원조달 계획 ②제도 및 행정개선계획	〃 〃	
		5.성과품 작성	①보고서작성 및 편집 ②관련도서작성	〃 〃	
		6.기술협의	①공청회 / 주민설명회 ②주민간담회 / 시민계획단 ③위원회 심의 지원 ④관계기관 협의	〃 〃 〃 〃	
	직접경비	여비, 인쇄비, 조감도, 회의준비비, 현장운영비 등		식	제1장 총칙참조
간접비	제경비	직접인건비×120%		〃	〃
	기술료	(직접인건비+제경비)×30%		〃	〃

주 : 공원녹지 기본계획에 관련되는 부수적인 업무인 조사, 측량, 개발타당성 조사검토, 토질조사 및 시험 및 생활권 공원·주제공원 등의 조성계획 입안, 각종영향평가 등과 같은 업무는 별도의 엔지니어링활동업무로 산정한다.

1-4-2 산정기준

1. 계획·기준인구의 설정

○ 기준인구는 전국의 시·군의 인구분포를 분석하여 인구 10만인으로 하였으며, 직능별 직접인력 소요원단위는 기 작성된 시·군 도시·군기본계획, 도시·군관리계획 등의 투입 기술자 비율을 감안하여 설정하였다.

○ 계획인구는 당해 도시권의 목표인구를 원칙으로 한다.

2. 표준품의 산정방법

○ 표준품의 적용에 있어 기준인구와 계획인구의 차이에 따른 품 산정은 아래의 수정식에 따라 기준인구의 소요작업량을 수정하여 산정한다.

○ 소요작업량 = 기준인구 소요작업량 × 인구보정계수(α)

3. 계획안의 수정과 과업중지에 따른 품 산정 방법

○ 계획안이 작성되고 주민공람, 지방의회보고 등 행정절차과정을 거쳐 계획안이 확정된 후 발주자의 사정에 의하여 계획안이 일부변경·재작업이 수행되는 경우에는 그 변경·재작업의 정도에 따라 엔지니어링사업대가의 50～100% 수준에서 비용을 추가 지급하여야 한다.

○ 과업수행 중 발주자의 사정에 따른 과업 중단으로 인해 정부 회계연도가 경과되어 현저한 비용의 차이가 발생하였을 경우에는 엔지니어링사업대가를 당해 신년도의 노임단가를 기준으로 재산정하여야 한다.

1-4-3 단위별 변화수정과 보정

1. 인구의 대소에 대한 작업량 보정계수 산정

○ 도시의 계획인구가 기준인구를 초과하거나 못 미치는 경우의 직접인력 소요작업량의 산정을 위한 보정계수(α)는 다음의 식에 의해 산정한다.

$$\alpha = \left(\frac{\text{계획인구}}{\text{기준인구}}\right)^{0.5} = \left(\frac{A}{10}\right)^{0.5}$$

α = 보정계수
A = 계획인구(만인)

계획단위 인구별 보정계수

계획인구(만인)	보정계수(α)	계획인구(만인)	보정계수(α)
10	1.000	100	3.162
15	1.225	120	3.464
20	1.414	150	3.873
30	1.732	200	4.472
50	2.236	400	6.325
70	2.646	500	7.071

주 : 계획인구가 기준인구(10만인)에 미달할 때에는 인구10만인을 기준으로 산정한다.

2. 직접인건비 소요 작업량 산정

○ 계획인구의 대소에 따른 직접인력 소요작업량의 산정방법은 아래와 같이 기준인구의 직능별 직접인력 소요작업량에 계획단위면적의 보정계수(α)를 곱하여 산출한다.

구 분	기준인구 (만인)	총작업량(인·일)					
		기술사	특 급	고 급	중 급	초 급	보조원
공원녹지 기본계획	10	41.8α	67.4α	159.3α	302.7α	367.7α	394.8α

1-5 표준단위 업무분류와 원단위

1-5-1 공원녹지 기본계획

기술업무의 직능별 직접인력 소요작업량(인구 10만인 기준)

(단위 : 인 · 일/표준단위)

구 분	업무내용	표준단위	소요인력						비고
			기술사	특 급	고 급	중 급	초 급	보조원	
1.기초자료 및 현황분석	①기초자료조사 및 수집 (간접조사)	10만인	5.4	9.0	20.0	44.0	80.0	80.0	
	②공원녹지여건분석	10만인	4.0	5.7	11.7	20.4	21.8	30.0	
	③종합분석 및 계획과제 도출	10만인	3.0	4.7	9.7	18.4	19.8	25.0	
	소 계		12.4	19.4	41.4	82.8	121.6	135.0	
2.기본구상	①계획의 목표및기본방향	10만인	3.0	4.8	10.5	17.5	18.0	19.7	
	②수요 및 공급계획	10만인	3.5	5.2	12.8	26.1	25.0	29.7	
	③공원녹지체계구상	10만인	3.5	6.0	14.3	23.5	25.0	29.5	
	소 계		10.0	16.0	37.6	67.1	68.0	78.9	
3.기본계획	①공원녹지종합배치계획	10만인	4.0	5.0	12.0	25.3	33.1	30.1	
	②공원녹지조성및정비계획	10만인	3.0	4.0	12.0	26.5	30.0	30.5	
	③도시녹화계획	10만인	3.0	4.9	12.0	24.9	26.7	25.7	
	④보전, 관리, 이용계획	10만인	3.5	4.0	12.0	25.7	29.0	30.0	
	⑤각종영향검토	10만인	1.0	3.0	8.0	12.0	17.5	20.0	
	소 계		14.5	20.9	56.0	114.4	136.3	136.3	
4.집행계획	⑥예산 및 재원조달계획	10만인	2.0	3.7	8.7	12.2	13.7	15.8	
	⑦제도 및 행정개선계획	10만인	1.4	3.4	7.7	10.1	10.9	8.4	
	소 계		3.4	7.1	16.4	22.3	24.6	24.2	
5.성과품작성	①보고서작성 및 편집	10만인	1.0	2.4	4.5	8.1	9.4	10.7	
	②관련도서작성	10만인	0.5	1.6	3.4	8.0	7.8	9.7	
	소 계		1.5	4.0	7.9	16.1	17.2	20.4	
총 계			41.8	67.4	159.3	302.7	367.7	394.8	
6.기술협의	①공청회/주민설명회	1식	2.0	2.0	2.0	4.0	4.0	4.0	
	②주민간담회/시민계획단	1식	2.0	2.0	2.0	4.0	4.0	4.0	
	③위원회심의 지원	1식	2.0	2.0	2.0	4.0	4.0	4.0	
	④관계기관 협의	1식	2.0	2.0	2.0	4.0	4.0	4.0	
	소 계		8.0	8.0	8.0	16.0	16.0	16.0	

주 : ①기초자료는 발주자가 제공하여야 하며 제공하지 못하는 자료에 대하여는 "기초조사항목별 세부내용"을 참조하여 별도 엔지니어링사업대가를 산정하며 본품은 발주자가 제공하는 기초조사 자료를 항목별로 분류하고 분석정리(간접조사)하는 경우에 한정하여 적용한다.

②기초 자료조사 및 수집에 관한 간접조사의 품은 「1-5-2 공원녹지 기본계획 기초조사(간접조사) 소요인력」을 참조한다

③각종영향평가 및 영향성검토(환경, 교통, 재해, 인구, 경관 등)를 본과업과 관련하여 필요로 할 때는 별도 발주하여야 하며 본품은 각종영향평가, 검토결과를 토대로 요약(재작성)할 경우에 한정하여 적용한다.

④기술협의는 2회 이내 기준이며, 횟수가 늘어날 경우 증가배수에 해당하는 작업품과 비용을 가산한다. (필요항목 선택적 적용)

1-5-2 공원녹지 기본계획 기초조사(간접조사)

기술업무의 직능별 직접인력 소요작업량(인구 10만인 기준)

(단위 : 인 · 일/표준단위)

업무내용	표준 단위	소요인력						비 고
		기술사	특 급	고 급	중 급	초 급	보조원	
1.지형·자원·생태 등 자연적 여건조사	10만인	1.8	3.0	6.0	9.0	18.0	18.0	
2.경관조사	10만인	1.2	2.0	4.0	6.0	12.0	12.0	
3.상위계획 등 관련계획 조사	10만인	0.3	0.5	1.0	2.0	3.0	3.0	
4.방재조사	10만인	0.3	0.5	1.0	2.0	5.0	5.0	
5.공원녹지 관련시설등 기타 필요사항	10만인	0.6	1.0	2.0	5.0	10.0	10.0	
6.성과품 작성	10만인	1.2	2.0	6.0	20.0	32.0	32.0	
총 계		5.4	9.0	20.0	44.0	80.0	80.0	

주 : 공원녹지 기본계획을 위한 「기초조사」의 해설

①직접조사 : 공원녹지 기본계획을 위한 기초조사 자료가 없는 경우로 별도의 품 적용 또는 견적과정을 거쳐 세부 항목별로 직접 인력이 투입되어 조사를 시행하는 과정으로 많은 조사 경비와 시간이 소요됨

②간접조사 : 발주자가 제공한 기초조사(직접조사)자료를 활용하여 분류·정리·분석하고 공원녹지 기본계획수립을 위한 기초조사 성과품을 작성하는 과정

1-5-3 공원녹지 기본계획 기초조사(직접조사)

기술업무의 직능별 직접인력 소요작업량(인구 10만인 기준)

(단위 : 인 · 일/표준단위)

업무내용	표준 단위	소요인력						비 고
		기술사	특 급	고 급	중 급	초 급	보조원	
1.이용실태 및 인식	10만인	5.3	8.7	20.6	37.5	42.4	44.5	
2.식생	10만인	7.0	10.3	22.8	40.5	44.1	47.3	
3.동물	10만인	6.0	9.5	21.8	39.2	43.5	46.8	
4.토양	10만인	5.6	8.7	19.3	38.4	42.0	45.5	
5.하천	10만인	4.2	9.1	19.5	37.5	43.2	46.3	
6.가로수	10만인	2.5	4.2	10.2	19.5	22.2	22.5	
7.공원시설물	10만인	2.8	4.5	10.4	18.0	20.2	22.0	
총 계		33.4	55.0	124.6	230.6	257.6	274.9	

주 : ①본 기초조사 직접인력 소요작업량은 공원녹지 기본계획 수립을 위한 기초조사 자료가 구축되어 있지 않을 경우, 직접조사를 위한 주요 공정의 인력 소요량을 예측한 자료이며, 이외에도 일반적인 업무내용이 아닐 경우는 별도의 품을 산정해야 한다.

②본 품은 각 분야별 전문품셈과 현저한 차이가 있을 경우 조정 가능함

③본 직접인력 소요량을 적용할 시에는 간접조사비용은 제외한다.

1-6 주요업무내용

1-6-1 공원녹지 기본계획 총괄업무내용

구 분	내 용
1.기초자료 조사 및 수립	·공원녹지기본계획을 수립하기 위한 여론조사, 생태조사(동식물, 토양, 하천 등) 가로수·공원시설물 조사 등 필요한 사항
2.공원녹지여건분석	·인문·사회환경 - 인구, 산업, 토지이용(공원, 녹지)등 ·자연환경 - 기후, 일반식생, 지형·지세·수계 등 ·기초 자료수집 사항의 분석 ·관련계획 및 법규검토
3.종합분석 및 계획과제	·문제점 분석 ·잠재력 도출 ·계획과제 제시
4.계획목표 및 기본방향	·계획목표제시 ·기본방향설정, 실행전략 수립
5.수요 및 공급계획	·인구대비, 공원녹지 수요분석 ·공원녹지 공급지표 설정 ·공원녹지 확보방안 제시
6.공원녹지의 체계구상	·환경보전, 여가이용 경관형성 등과 관련시켜 공원녹지의 축을 설정 ·수계, 바람길, 생태통로, 공원간 연계이용 등을 고려한 공원녹지 연결망계획 수립 ·도시환경개선, 생물서식 환경유지 여가공간제공, 경관형성 등을 고려한 공원녹지의 체계 기본구상안 제시
7.공원녹지 종합배치 계획	·녹지의 보전과 활용계획 ·도시공원 확보 및 기능별 배치계획 ·시가지 녹지의 확보 및 기능별 배치계획 (가로환경, 하천환경, 공공시설지 녹화)
8.공원녹지 조성 및 정비계획	·도시공원재편, 확충계획 ·자연공원구역, 시설녹지 정비계획 ·생활권 공원, 주제공원별 특화계획
9.도시녹화계획	·녹화사업별 계획 ·단계별 녹화계획 ·시민참여 및 지원방향
10.보전관리, 이용계획	·공원녹지 보전계획 ·공원녹지 관리체계 개선 ·이용활성화 계획
11.각종 영향 검토	·환경·교통·재해, 인구, 경관 등 기초자료 또는 별도 업무의 자료검토 및 반영
12.예산 및 재원조달계획	·공원녹지 소요예산 ·재원 확보방안
13.제도 및 행정개선계획	·관련제도 개선방향 ·공원녹지 행정개선 계획
14.성과품 작성	

1-6-2 기초조사항목별 세부내용

항 목	내 용	비 고
1.여론조사	·공원녹지이용실태 및 인식조사	·실비적용(전문업체 의뢰)
	·조사방법 : 면담, 설문, 전화 등 적정방법 선택 ·조사대상 : 인구대비 일정표본(sample) 조사	
2.생태조사	·식생조사 (주요 식물상 및 식물분포) ·동물조사 (특정종의 분포 및 서식지) ·토양조사 (토양단면구조와 이화학적 특성) ·하천조사 (수자원의 규모와 특성)	·실비적용(전문가 또는 전문업체 의뢰)
	·조사방법 : 현지 또는 문헌조사 ·조사대상 : 특정 또는 대표지역의 표본(sample) 조사	
3.전수조사	·가로수 조사 (도로변 가로수) ·시설물 조사 (공원시설물)	·실비적용
	·조사방법 : 현지 또는 자료조사 ·조사대상 : 전체 또는 특정지역의 전수조사	

1-7 표준성과품

성과구분	표준성과도서			비 고
	구 분	규 격	제출 부수	
현황도	·위치도 ·기초조사결과(도) ·주요시설현황도 ·현황종합분석도	1/25,000~1/50,000 1/25,000~1/50,000 1/25,000~1/50,000 1/25,000~1/50,000	1부 1부 1부 1부	
계획도	·공원·녹지체계구상도 ·공원·녹지 기본계획도	1/25,000~1/50,000 1/25,000~1/50,000 1/25,000~1/50,000	2부 2부 2부	
보고서	·공원녹지 기본계획 보고서 ·공청회개최 의견조치내용 ·공원녹지 기본계획수립에 이용된 자료			발주자와 협의

주 : ①제출부수 및 성과품 종류가 증가할 경우에는 증가배수에 해당하는 작업품과 비용을 가산한다.
②계획보고서 및 기타 관련 자료의 규격 및 제출부수는 발주자와의 협의에 의하여 비용을 산정한다.
③「기초조사결과」에 대한 성과품 내용은 발주자가 제공한 자료를 바탕으로 한 간접조사 자료 정리 결과이며, 제공 자료가 없을 경우에는 별도로 품을 가산하여야 한다.

제2절 도시녹화계획

2-1 정 의

○ 도시녹화계획은 「도시공원 및 녹지 등에 관한 법률」제11조와 시행령 제9조의 규정에 의하여 공원녹지기본계획수립권자가 공원녹지기본계획을 통하여 수립된 도시녹화와 관련된 계획을 토대로 도시지역의 일부에 대한 녹지의 보전 및 확충이 특별히 필요한 지역의 설정과 도시녹화에 관한 정비계획을 말한다.

2-2 자료제공의 전제

○ 도시녹화계획에 필요한 모든 관련자료(도시의 지형·자원·생태 등 자연여건자료, 경관조사자료, 상위계획, 공원녹지 관련 등)는 원칙적으로 발주자가 제공하는 것으로 한다.

○ 발주자가 제공하지 못하는 자료의 조사에 있어서는 그 규모·내용에 의거하여 별도의 엔지니어링사업대가를 산정하여 엔지니어링사업자가 수행하며, 관련 자료의 기밀성과 광범위한 자료가 요구되는 경우 조사·분석에 필요한 상당기간과 자료수집비용이 전제되어야 한다.

2-3 업무범위와 추진과정

2-3-1 업무범위

○ 도시녹화계획은 「도시공원 및 녹지에 관한 법률」 제3장 제11조 및 시행령 제9조에 규정한 내용을 주요업무 범위로 한다.

2-3-2 추진과정

○ 타 부처(관계기관)와의 협의나 전문가 자문 등에 소요되는 기간은 과업수행기간에서 제외하여 그 소요기간만큼 과업수행기간을 연장하여야 한다.

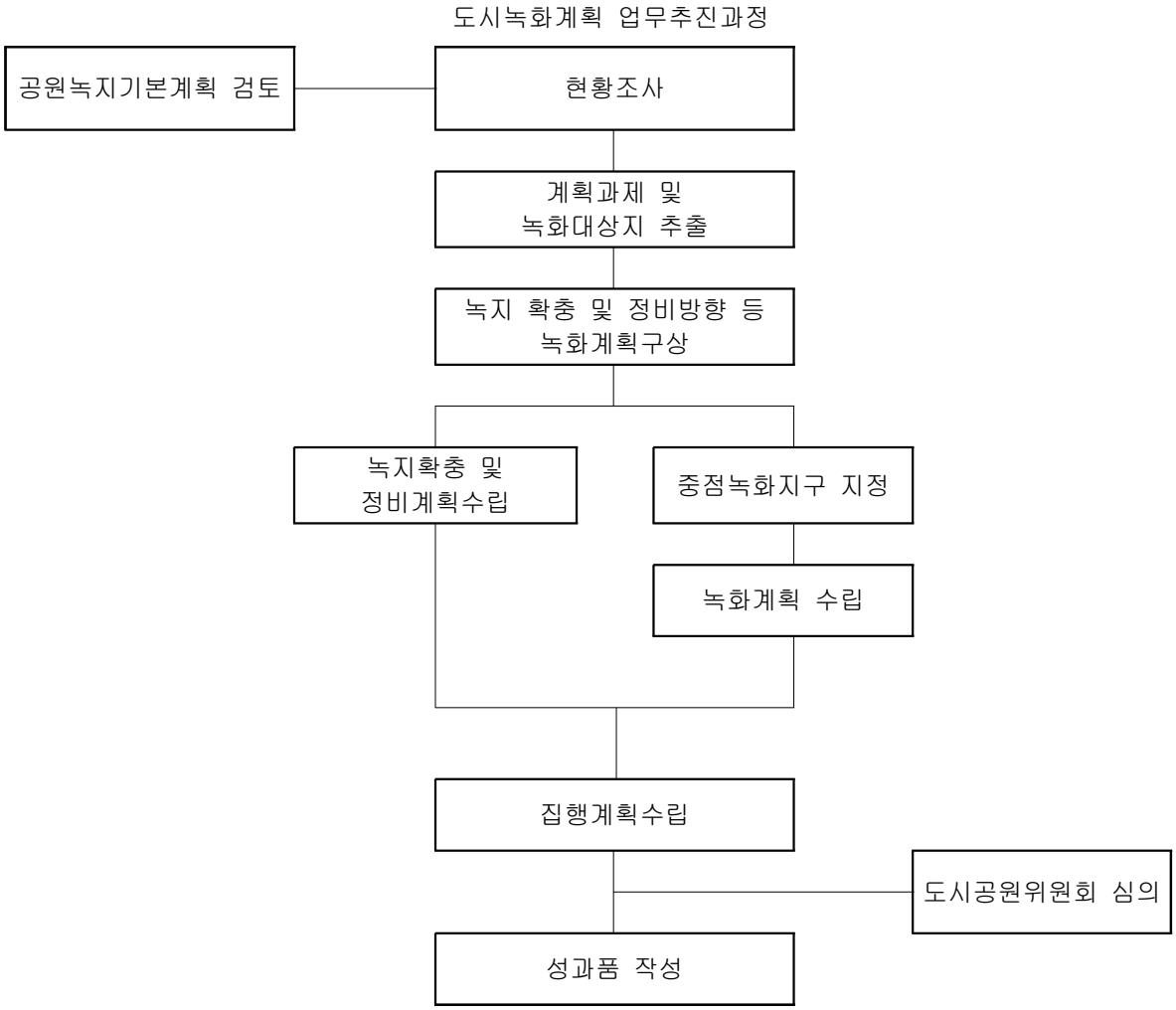

2-4 품 산정의 원단위 산정과 기준

2-4-1 표준품 산정내역

○ 표준품 산정의 기준이 되는 비목은 제1장 총칙에서 제시한 비목을 중심으로 하였으며, 이는 도시녹화계획에 필요한 사항만을 대상으로 한다.

○ 표준품 산정의 기본이 되는 직접인건비 품의 작업항목별 보할은 업무의 난이도를 감안하여 설정토록 한다.

1. 도시녹화계획의 수립을 위한 현황조사

○ 대상 행정구역 지역의 현황조사는 공원녹지기본계획 수립을 위해 수집된 기초조사 자료를 사용하며 추가로 필요한 조사에 대해서는 별도의 품을 적용한다.

2. 도시녹화계획의 표준산정내역

종 별		내 용	세부항목	단 위	비 고
직접비	직접인건비	1.현황조사	①기 수집 자료조사 및 분석 ②녹지분포 및 이용현황 조사 ③종합분석 및 계획과제 도출	인·일 〃 〃	
		2.녹화계획구상	①계획의 목표 설정 ②기본방향 및 테마, 미래상 ③녹지의 확충 및 정비 방안 ④중점녹화지구 지정	〃 〃 〃 〃	
		3.녹지확충 및 정비계획	①종합배치계획 ②지구별 녹화계획 ③대상지별 녹화의 목표 및 조성지침 제시	〃 〃 〃	
		4.중점녹화지구 지정 및 녹화계획	①중점지구 녹화과제 도출 ②녹화의 방향 및 구상 ③녹화계획 수립	〃 〃 〃	
		5.집행계획	①예산 및 재원조달계획 ②녹화프로그램 산정 ③녹화보급 활동계획 수립	〃 〃 〃	
		6.성과품 작성	①보고서작성 및 편집 ②관련도서작성	〃 〃	
		7.기술협의	①공청회 / 주민설명회 ②주민간담회 / 시민계획단 ③위원회 심의 지원 ④관계기관 협의	〃 〃 〃 〃	
	직접경비	여비, 인쇄비, 조감도, 회의준비비, 현장운영비 등		식	제1장 총칙참조
간접비	제경비	직접인건비×120%		〃	〃
	기술료	(직접인건비+제경비)×30%		〃	〃

2-4-2 산정기준

1. 계획·기준면적의 설정

○ 기준면적은 전국의 공원녹지기본계획수립 해당 시·군의 행정구역 면적의 분포를 분석하여 100㎢로 하였으며, 직능별 직접인력 소요원단위는 기 작성된 시·군 도시·군기본계획, 시·군 공원녹지기본계획 등의 투입기술자 비율을 감안하여 설정하였다.

○ 계획의 기준면적은 시·군의 관할 행정구역을 원칙으로 한다.

2. 표준품의 산정방법

○ 표준품의 적용에 있어 기준면적과 계획면적의 증감에 따른 품 산정은 아래의 수정식에 따라 기준면적의 소요작업량을 수정하여 산정한다.

○ 소요작업량 = 기준면적 소요작업량 × 면적보정계수(α)

3. 계획안의 수정과 과업중지에 따른 산정방법

○ 계획안이 작성되고 시·군 도시공원위원회의 심의 등 행정절차과정을 거쳐 계획안이 확정된 후 발주자의 사정에 의하여 계획안이 일부변경·재작업이 수행되는 경우에는 그 변경·재작업의 정도에 따라 엔지니어링사업대가의 50～100% 수준에서 비용을 추가 지급하여야 한다.

○ 과업수행 중 발주자의 사정에 따른 과업 중단으로 인해 정부 회계연도가 경과되어 현저한 비용의 차이가 발생하였을 경우에는 엔지니어링사업대가를 당해 신년도의 노임단가를 기준으로 재산정하여야 한다.

2-4-3 단위별 변화수정과 보정

1. 면적의 대소에 대한 작업량 보정계수 산정

○ 도시의 계획기준면적을 초과하거나 못 미치는 경우의 직접인력 소요작업량의 산정을 위한 보정계수(α)는 다음의 식에 의해 산정한다.

$$\alpha = \left(\frac{\text{계획면적}}{\text{기준면적}}\right)^{0.5} = \left(\frac{A}{100}\right)^{0.5}$$

α = 보정계수
A = 계획면적(㎢)

계획단위 면적별 보정계수

계획면적(㎢)	보정계수(α)	계획면적(㎢)	보정계수(α)
50	0.707	300	1.732
100	1.000	350	1.870
150	1.224	400	2.000
200	1.414	450	2.121
250	1.581	500	2.236

주 : 계획면적이 50㎢에 미달할 때에는 계획면적 50㎢을 기준으로 산정한다.

2. 직접인건비 소요 작업량 산정

○ 계획면적의 대소에 따른 직접인력 소요작업량의 산정방법은 아래와 같이 기준면적의 직능별 직접인력 소요작업량에 계획단위면적의 보정계수(α)를 곱하여 산출한다.

구 분	기준면적 (㎢)	총작업량(인·일)					
		기술사	특 급	고 급	중 급	초 급	보조원
도시녹화계획	100	49.5α	80.3α	190.8α	363.2α	438.5α	467.4α

2-5 표준단위 업무분류와 원단위

기술업무의 직능별 직접인력 소요작업량(면적 100㎢기준)

(단위 : 인 · 일/표준단위)

구 분	업무내용	표준단위	소요인력						비고
			기술사	특 급	고 급	중 급	초 급	보조원	
1.현황조사	①기수립 자료 조사 및 분석	100㎢	5.4	9.0	20.0	44.0	80.1	80.0	
	②녹지분포 및 이용현황조사	100㎢	4.0	5.7	11.7	20.4	21.8	30.0	
	③종합분석 및 계획과제도출	100㎢	3.0	4.7	9.7	18.4	19.8	25.0	
	소 계		12.4	19.4	41.4	82.8	121.7	135.0	
2.녹화계획 구상	①계획의 목표 설정	100㎢	3.0	4.8	10.5	17.5	18.0	19.7	
	②기본방향 및 테마, 미래상	100㎢	3.5	5.2	12.8	26.1	25.0	29.7	
	③녹지의 확충 및 정비 방안	100㎢	3.2	5.0	10.4	20.2	23.5	25.5	
	④중점녹화지구 지정	100㎢	3.5	6.0	14.3	23.5	25.0	29.5	
	소 계		13.2	21.0	48.0	87.3	91.5	104.4	
3.녹지확충 및 정비계획	①종합배치계획	100㎢	4.0	5.0	12.0	25.3	33.1	30.1	
	②지구별 녹화계획	100㎢	3.0	4.0	12.0	26.5	30.0	30.5	
	③대상지별 녹화의 목표 및 조성 지침 제시	100㎢	2.0	3.9	11.0	22.5	23.6	22.5	
	소 계		9.0	12.9	35.0	74.3	86.7	83.1	
4.중점녹화지 구지정 및 녹화계획	①중점지구 녹화과제 도출	100㎢	2.5	3.0	10.0	20.8	25.0	28.0	
	②녹화의 방향 및 구상	100㎢	2.8	4.0	10.6	21.5	24.6	23.5	
	③녹화계획 수립	100㎢	3.0	4.9	12.0	24.9	26.7	25.7	
	소 계		8.3	11.9	32.6	67.2	76.3	77.2	
5.집행계획	①예산 및 재원조달계획	100㎢	2.0	3.7	8.7	12.2	13.7	15.8	
	②녹화프로그램 산정	100㎢	1.2	3.0	7.0	9.2	10.1	10.8	
	③녹화보급활동계획 수립	100㎢	1.4	3.4	7.7	10.1	10.9	8.6	
	소 계		4.6	10.1	23.4	31.5	34.7	35.2	
6.성과품 작성	①보고서작성 및 편집	100㎢	1.5	3.0	5.9	10.1	15.2	17.0	
	②관련도서 작성	100㎢	0.5	2.0	4.5	10.0	12.5	15.5	
	소 계		2.0	5.0	10.4	20.1	27.7	32.5	
총 계			49.5	80.3	190.8	363.2	438.5	467.4	
7.기술협의	①공청회/주민설명회	1식	2.0	2.0	2.0	4.0	4.0	4.0	
	②주민간담회/시민계획단	1식	2.0	2.0	2.0	4.0	4.0	4.0	
	③위원회심의 지원	1식	2.0	2.0	2.0	4.0	4.0	4.0	
	④관계기관 협의	1식	2.0	2.0	2.0	4.0	4.0	4.0	
	소 계		8.0	8.0	8.0	16.0	16.0	16.0	

주 : ①도시녹화계획에 필요한 기초 자료는 해당 도시의 공원녹지기본계획수립시 조사된 내용을 발주자가 제공하여야 하며 제공하지 못하는 자료에 대하여는 「1-5-2 공원녹지 기본계획 기초조사(간접조사) 소요인력」 및 「1-5-3 공원녹지 기본계획 기초조사(직접조사) 소요인력」을 참조하여 별도의 엔지니어링 사업대가를 산정한다.

②각종영향성검토 및 각종영향평가업무는 별도의 엔지니어링활동업무로 계상한다.

③기술협의는 2회 이내 기준이며, 횟수가 늘어날 경우 증가배수에 해당하는 작업품과 비용을 가산한다. (필요항목 선택적 적용)

2-6 주요업무내용

구 분	내 용
1.현황조사	·공원녹지기본계획관련 기초 조사자료의 수집 및 분석 ·인구, 면적 등 도시개요 및 녹지현황 ·토지이용 및 시설현황 ·수림지, 농지, 수면 등의 오픈스페이스 현황 및 존속성 ·녹지분포상황, 철로변, 하천, 도로 등의 선형녹지 현황 ·지역주민의 녹화활동 참여현황 등 ·종합분석 및 계획과제의 도출 ·녹화대상지의 추출
2.녹화계획구상	·계획의 목표(목표량, 목표기간 등) 설정 ·기본방향 제시 및 테마, 미래상 설정 ·녹화공간 배치방침 ·녹지의 확충 및 정비방안 ·중점녹화지구 지정
3.녹지확충 및 정비계획	·녹지 확충 및 배치계획 ·지구별 녹화계획 ·공공시설녹지의 녹화 목표 및 조성지침 제시 ·사유지의 녹화목표 및 조성지침 제시
4.중점녹화지구 지정 및 녹화계획	·중점녹화지구의 계획과제 도출 ·녹화의 기본방향 설정, 실행전략 수립 ·중점녹화지구 녹화정비계획 수립
5.집행계획	·소요예산 및 재원조달계획 ·녹화사업 및 활동 프로그램 산정 ·시민참여 및 협력방안 ·녹화보급 활동계획 수립
6.성과품 작성	

2-7 표준성과품

성과구분	표준성과도서			비 고
	구 분	규 격	제출부수	
보고서	·중간보고서 ·최종보고서 ·요약보고서 ·조사자료집		각30부	
도면	·도시녹화계획총괄도	1/25,000~1/50,000	2부	
기타	·관련법규에 의한 도면			발주자와 협의

주 : ①제출부수 및 성과품 종류가 증가할 경우에는 증가배수에 해당하는 작업품과 비용을 가산한다.
②계획보고서 및 기타 관련자료의 규격 및 제출부수는 발주자와의 협의에 의하여 비용을 산정한다.
③조사자료집에 대한 성과품 내용은 발주자가 제공한 자료를 바탕으로 한 간접조사 자료 정리 결과이며, 제공 자료가 없을 경우에는 별도로 품을 가산하여야 한다.

제3절 공원계획

3-1 정 의

○ 공원계획은 자연공원법에 의한 국립공원, 도립공원, 군립공원과 도시공원 및 녹지등에 관한 법률에 의한 도시자연공원구역, 생활권 공원(소공원, 어린이공원, 근린공원), 주제공원(역사공원, 문화공원, 수변공원, 묘지공원, 체육공원, 도시농업공원 그 밖에 특별시·광역시·도의 조례로 정하는 공원)을 포함하며, 공원의 보전 및 이용을 증진하기 위하여 필요한 행위의 제한과 공원시설 전반에 관한 계획 그리고 타당성 검토를 말한다.

○ 또한, 기타 공원계획과 유사한 과업으로 공원리모델링은 기존공원에 대한 유지, 보수, 개수 등 공원기능을 재향상시키는 계획을 말하며, 지역테마길은 '둘레길' 등과 같은 특정테마의 길, 옛거리, 폐도, 폐철도 등을 활용한 휴식, 산책, 공원 등의 기능을 제고하는 길관련 사업을 말한다.

3-2 자료제공의 전제

○ 공원계획에 필요한 모든 관련자료(기본도면 및 공원지형고시 도면(1/5,000이상)는 원칙적으로 발주자가 제공하는 것으로 하되, 발주자가 보유하지 않는 자료는 엔지니어링사업자가 조사·수집한다.

○ 발주자가 제공하지 못하는 자료의 조사에 있어서는 그 규모·내용에 의거하여 별도의 엔지니어링사업대가를 산정하여 엔지니어링사업자가 수행하며, 당해 관련 자료의 기밀성과 광범위한 자료가 요구될 경우는 조사·분석에 필요한 상당기간과 자료수집비용이 전제되어야 한다.

3-3 업무범위와 추진과정

3-3-1 업무범위

1. 자연공원

○ 자연공원계획은 기본계획, 기본설계, 실시설계 등을 주요업무범위로 한다.

2. 도시공원

○ 도시공원계획은 기본계획, 기본설계, 실시설계 등을 주요업무범위로 한다.

3-3-2 추진과정

○ 타 부처(관계기관)와의 협의나 전문가 자문 등에 소요되는 기간은 과업수행기간에서 제외하면 그 소요기간만큼 과업수행기간을 연장하여야 한다.

공원계획 업무추진과정

3-4 품 산정의 원단위 산정과 기준

3-4-1 표준품 산정내역

○ 표준품 산정의 기준이 되는 비목은 제 1장 총칙에서 제시한 비목을 중심으로 하였으며, 이는 공원계획에 필요한 사항만을 대상으로 한다.

○ 표준품 산정의 기본이 되는 직접인건비 품의 작업항목별 보할은 업무의 난이도를 감안하여 설정토록 한다.

1. 조사 및 측량, 토질조사 및 시험

○ 측량 및 토질조사 품 별도 적용

2. 기본계획의 표준 산정내역

1) 자연공원

종 별		내 용	세부항목	단 위	비 고
직접비	직접인건비	1.개발여건분석	①자연환경 ②인문환경 ③종합분석	인·일 〃 〃	
		2.기본구상	①개발방향설정 ②계획지표설정 ③토지이용체계 ④동선체계구상 ⑤유치시설종류 및 규모설정	〃 〃 〃 〃 〃	
		3.기본계획(부문별)	①공원용도지구계획 ②공원보전계획 ③공원시설계획 ④공원관리계획	〃 〃 〃 〃	
		4.사업계획	①개발추진계획 ②관리운영계획	〃 〃	
		5.성과품 작성	①보고서작성 및 편집 ②관련도서작성	〃 〃	
		6.기술협의	①공청회 / 주민설명회 ②주민간담회 / 시민계획단 ③위원회심의 지원 ④관계기관 협의	〃 〃 〃 〃	
	직접경비	여비, 인쇄비, 조감도, 회의준비비, 현장운영비 등		식	제1장 총칙참조
간접비	제경비	직접인건비×120%		〃	〃
	기술료	(직접인건비+제경비)×30%		〃	〃

주 : 공원계획에 관련되는 부수적인 업무인 조사, 측량, 개발타당성 조사검토, 토질조사 및 시험, 공원외의 인입시설, 하수처리장 설계, 각종 영향평가 등과 같은 업무는 별도의 엔지니어링활동업무로 산정한다.

2) 도시공원

종 별		내 용	세부항목	단 위	비 고
직접비	직접인건비	1.개발여건분석	①자연환경 ②인문환경 ③종합분석	인·일 〃 〃	
		2.기본구상	①개발방향설정 ②계획지표설정 ③토지이용체계 ④동선체계구상 ⑤유치시설종류 및 규모 설정	〃 〃 〃 〃 〃	
		3.기본계획	①토지이용계획 ②교통동선계획 ③시설물배치계획 ④식재계획 ⑤공급처리시설계획	〃 〃 〃 〃 〃	
		4.사업계획	①개발추진계획 ②관리운영계획	〃	
		5.성과품 작성	①보고서작성 및 편집 ②관련도서작성	〃 〃	
		6.기술협의	①공청회 / 주민설명회 ②주민간담회 / 시민계획단 ③위원회심의 지원 ④관계기관 협의	〃 〃 〃 〃	
	직접경비	여비, 인쇄비, 조감도, 회의준비비, 현장운영비 등		식	제1장 총칙참조
간접비	제경비	직접인건비×120%		〃	〃
	기술료	(직접인건비+제경비)×30%		〃	〃

주 : 공원계획에 관련되는 부수적인 업무인 조사, 측량, 개발타당성 조사검토, 토질조사 및 시험, 공원외의 인입시설, 하수처리장 설계, 각종 영향평가 등과 같은 업무는 별도의 엔지니어링활동업무로 산정한다.

3. 기본설계, 실시설계의 표준산정내역

○ 기본설계와 실시설계의 품 산정은 엔지니어링대가의 기준 중 건설부문 공사비 요율을 적용한다.

3-4-2 산정기준

1. 계획기준면적의 설정

○ 기준면적의 설정을 위해 이미 지정된 자연공원 및 도시공원의 면적분포 현황을 분석하여 빈도가 가장 높은 것을 기준면적으로 산정 하였다.

○ 공원별 기준 면적

구 분			기준면적
자연공원		·국립공원	100㎢(30,250,000평)
		·도립공원	30㎢(9,075,000평)
		·군립공원	5㎢(1,512,500평)
도시공원	생활권 공원	·소공원, 어린이공원	0.25만㎡(756평)
		·근린공원	10만㎡(30,250평)
	주제공원	·역사공원	10만㎡(30,250평)
		·문화공원	10만㎡(30,250평)
		·수변공원	10만㎡(30,250평)
		·묘지공원	10만㎡(30,250평)
		·체육공원	10만㎡(30,250평)
		·도시농업공원	10만㎡(30,250평)
		·도시자연공원구역	30만㎡(60,500평)
기타		·공원리모델링	10만㎡(30,250평)
		·지역테마길	10만㎡(30,250평)

○ 계획면적은 고시된 경우는 법정계획면적을, 신설된 경우는 기본구상을 전제로 한 조사면적을 기준으로 하되, 다음의 경우에는 공원계획의 계획면적에 포함한다.

- 강, 바다 등을 포함하는 지역은 강, 바다 등의 시설지구로 이용될 때 계획면적에 포함함을 원칙으로 한다.
- 자연공원법에 의한 자연공원특별보호구역도 공원계획면적에 포함함을 원칙으로 한다.
- 도시공원 및 녹지 등에 관한 법률에 의한 주제공원 중 특별시·광역시 또는 도의 조례가 정하는 공원은 근린공원 기준면적을 준용한다.

2. 표준품의 산정방법

○ 표준품의 적용에 있어 기준면적과 차이에 따른 품 산정은 아래의 수정식에 따라 기준면적의 소요작업량을 수정하여 산정한다.

소요작업량 = 기준면적소요작업량 × 면적보정계수(α)

3. 계획안의 수정과 과업중지에 따른 산정방법

○ 계획안이 작성되고 주민공람, 의회보고, 시·도 도시공원위원회 심의 등 행정절차과정을 거쳐 계획안이 확정된 후 발주자의 사정에 의하여 계획안이 일부변경·재작업이 수행되는 경우에는 그 변경·재작업의 정도에 따라 엔지니어링사업대가의 50～100% 수준에서 비용을 추가 지급하여야 한다.

○ 과업수행 중 발주자의 사정에 따른 과업 중단으로 인해 정부 회계연도가 경과되어 현저한 비용의 차이가 발생하였을 경우에는 엔지니어링사업대가를 당해 신년도의 노임단가를 기준으로 재산정하여야 한다.

3-4-3 단위별 변화수정과 보정

1. 면적의 대소에 대한 작업량 보정계수 산정

○ 계획면적이 기준면적을 초과하거나 못 미치는 경우의 직접인력 소요작업량의 산정을 위한 면적보정계수(α)는 다음의 식에 의해 산정한다.

구 분		보정계수(α)	비 고
자연공원	·국립공원	$\alpha = \left(\frac{\text{계획면적}}{\text{기준면적}}\right)^{0.5} = \left(\frac{A}{100}\right)^{0.5}$	A : 계획면적(㎢) α : 보정계수
	·도립공원	$\alpha = \left(\frac{\text{계획면적}}{\text{기준면적}}\right)^{0.5} = \left(\frac{A}{30}\right)^{0.5}$	
	·군립공원	$\alpha = \left(\frac{\text{계획면적}}{\text{기준면적}}\right)^{0.5} = \left(\frac{A}{5}\right)^{0.5}$	
도시공원 및 기타	소공원, 어린이공원	$\alpha = \left(\frac{\text{계획면적}}{\text{기준면적}}\right)^{0.6} = \left(\frac{A}{0.25}\right)^{0.6}$	A : 계획면적(만㎡) α : 보정계수
	근린공원, 주제공원 공원리모델링, 지역테마길	$\alpha = \left(\frac{\text{계획면적}}{\text{기준면적}}\right)^{0.6} = \left(\frac{A}{10}\right)^{0.6}$	
	도시자연공원구역	$\alpha = \left(\frac{\text{계획면적}}{\text{기준면적}}\right)^{0.6} = \left(\frac{A}{30}\right)^{0.6}$	

자연공원의 계획면적별 보정계수

국 립 공 원			도 립 공 원			군 립 공 원		
면적(A)		보정계수	면적(A)		보정계수	면적(A)		보정계수
㎢	천평	(α)	㎢	천평	(α)	㎢	천평	(α)
30	9,075	0.548	10	3,025	0.577	2.0	605	0.632
40		0.632	11		0.592	2.5		0.707
50		0.707	12		0.632	3.0		0.775
60		0.775	13		0.663	3.5		0.837
70		0.837	14		0.671	4.0		0.894
80		0.894	15		0.707	4.5		0.949
90		0.949	16		0.730	5.0	1,512.5	1.000
100	30,250	1.000	17		0.742	6.0		1.095
110		1.049	18		0.775	7.0		1.183
120		1.095	19		0.796	8.5		1.265
130		1.140	20	6,050	0.816	9.0		1.342
140		1.183	25		0.908	10.0	3,025	1.414
150		1.225	30	9,075	1.000	15.0		1.732
160		1.265	35		1.072	20.0		2.000
170		1.304	40		1.155	25.0		2.236
180		1.342	45		1.225	30.0		2.449
190		1.378	50	15,125	1.291	35.0		2.646
200	60,500	1.414	55		1.354	40.0		2.828
210		1.449	60		1.414	45.0		3.000
220		1.483	65		1.483	50.0	15,125	3.162
230		1.517	70		1.528			
240		1.549	75		1.581			
250	75,625	1.581	80		1.628			
260		1.612	85		1.683			
270		1.643	90		1.732			
280		1.673	95		1.775			
290		1.703	100	30,250	1.826			
300	90,750	1.732						
350		1.871						
400		2.000						
450		1.121						
500	151,250	2.236						

※국립공원 계획면적이 30㎢ 미만이면 보정계수는 30㎢에 준한다.

※도립공원 계획면적이 10㎢ 미만이면 보정계수는 10㎢에 준한다.

※군립공원 계획면적이 2.0㎢ 미만이면 보정계수는 2.0㎢에 준한다.

도시공원(소공원, 어린이공원)의 계획면적별 보정계수

면적(A)		보정계수(α)
만㎡	천평	
0.15	0.45	0.736
0.25	0.76	1.000
0.50	1.51	1.516
0.75	2.27	1.933
1.00	3.02	2,297

※소공원, 어린이공원의 면적이 0.15만㎡미만인 경우에는 0.15만㎡의 보정계수를 적용한다.

도시공원(근린공원, 주제공원)의 계획면적별 보정계수

면적(A)		보정계수(α)	면적(A)		보정계수(α)	면적(A)		보정계수(α)
만㎡	천평		만㎡	천평		만㎡	천평	
5	15.125	0.660	14		1.224	35		2.121
6		0.736	15		1.275	40		2.297
7		0.807	16		1.326	45		2.466
8		0.875	17		1.375	50	151.250	2.627
9		0.939	18		1.423	60		2.930
10	30.250	1.000	19		1.470	70		3.214
11		1.059	20	60.500	1.516	80		3.482
12		1.116	25		1.733	90		3.737
13		1.170	30		1.933	100	302.500	3.981

※근린공원, 주제공원(역사, 문화, 수변, 묘지, 체육공원, 도시농업)의 계획면적이 5만㎡미만인 경우에는 5만㎡의 보정계수를 적용한다.

도시자연공원구역의 계획면적별 보정계수

면적(A)		보정계수 (α)	면적(A)		보정계수 (α)	면적(A)		보정계수 (α)
만㎡	천평		만㎡	천평		만㎡	천평	
10	30.250	0.517	19		0.760	70		1.663
11		0.548	20	60.500	0.784	80		1.801
12		0.577	25		0.896	90		1.933
13		0.605	30	90.750	1.000	100	302.500	2.059
14		0.633	35		1.097	120		2.297
15	45.375	0.660	40		1.188	150		2.627
16		0.686	45		1.275	200		3.121
17		0.711	50	151.250	1.359	250		3.569
18		0.736	60		1.516	300	907.450	3.981

※도시자연공원구역의 계획면적이 10만㎡미만인 경우에는 10만㎡의 보정계수를 적용한다.

2. 직접인건비 소요 작업량 산정

○ 계획면적의 대소에 따른 직접인력 소요작업량의 산정방법은 아래와 같이 기준면적의 직능별 소요작업량에 계획단위 보정계수(α)를 곱하여 산출한다.

구 분		기준면적	총작업량(인·일)					
			기술사	특 급	고 급	중 급	초 급	보조원
자연공원	국립공원	100㎢	61.0α	95.0α	326.0α	422.0α	548.0α	773.0α
	도립공원	30㎢	33.0α	52.0α	178.0α	231.0α	300.0α	423.0α
	군립공원	5㎢	14.0α	21.0α	73.0α	95.0α	123.0α	173.0α
도시공원 및 기타	소공원, 어린이공원	0.25만㎡	1.0α	1.0α	2.0α	3.0α	4.0α	8.0α
	근린공원, 주제공원, 공원리모델링, 지역테마길	10만㎡	17.0α	25.0α	86.0α	111.0α	122.0α	158.0α
	도시자연 공원구역	30만㎡	14.0α	21.0α	73.0α	95.0α	123.0α	173.0α

3-5 표준단위 업무분류와 원단위

3-5-1 기술업무의 직종별 인력 소요작업량

1. 자연공원

1) 국립공원(100㎢ 기준)

(단위 : 인 · 일/표준단위)

구 분	업무내용	표준단위	소요인력						비고
			기술사	특 급	고 급	중 급	초 급	보조원	
1.개발여건 분석	①자연환경	100㎢	4.4	6.6	16.3	21.3	27.4	47.3	
	②인문환경	100㎢	4.3	16.2	16.2	21.3	27.4	47.3	
	③종합분석	100㎢	4.3	19.5	19.5	21.4	33.2	47.4	
	소 계		13.0	20.0	52.0	64.0	88.0	142.0	
2.기본구상	①개발방향설정	100㎢	1.8	2.9	16.2	25.2	27.4	46.8	
	②계획지표설정	100㎢	1.8	2.9	16.2	25.2	32.9	46.8	
	③토지이용체계	100㎢	2.5	3.7	16.2	25.2	32.9	46.8	
	④동선체계구상	100㎢	2.5	3.7	16.2	25.2	32.9	46.8	
	⑤유치시설종류 및 규모설정	100㎢	2.4	3.8	16.2	25.2	32.9	46.8	
	소 계		11.0	17.0	81.0	126.0	159.0	234.0	
3.기본계획 (부문별)	①공원용도지구계획	100㎢	3.7	5.7	23.0	25.0	43.6	54.0	
	②공원보전계획	100㎢	3.7	5.7	23.0	25.0	43.6	54.0	
	③공원시설계획	100㎢	8.9	13.9	49.0	62.0	87.2	123.5	
	④공원관리계획	100㎢	3.7	5.7	23.0	25.0	43.6	69.5	
	소 계		20.0	31.0	118.0	137.0	218.0	301.0	
4.사업계획	①개발추진계획	100㎢	8.0	12.0	36.0	38.0	27.5	38.0	
	②관리운영계획	100㎢	6.0	10.0	26.0	35.0	27.5	30.0	
	소 계		14.0	2.0	62.0	73.0	55.0	68.0	
5.성과품 작성	①보고서작성 및 편집	100㎢	2.3	3.9	9.8	13.1	11.2	5.0	
	②관련도서작성	100㎢	0.7	1.1	3.2	8.9	16.8	23.0	
	소 계		3.0	5.0	13.0	22.0	28.0	28.0	
총 계			61.0	95.0	326.0	422.0	548.0	773.0	
6.기술협의	①공청회/주민설명회	1식	2.0	2.0	2.0	4.0	4.0	4.0	
	②주민간담회/시민계획단	1식	2.0	2.0	2.0	4.0	4.0	4.0	
	③위원회심의 지원	1식	2.0	2.0	2.0	4.0	4.0	4.0	
	④관계기관 협의	1식	2.0	2.0	2.0	4.0	4.0	4.0	
	소 계		8.0	8.0	8.0	16.0	16.0	16.0	

주 : ①기술협의는 2회 이내 기준이며, 횟수가 늘어날 경우 증가배수에 해당하는 작업품과 비용을 가산한다. (필요항목 선택적 적용).

②각종영향성검토 및 각종영향평가업무는 별도의 엔지니어링활동업무로 계상한다.

2) 도립공원(30㎢ 기준)

(단위 : 인 · 일/표준단위)

구 분	업무내용	표준단위	소요인력						비고
			기술사	특 급	고 급	중 급	초 급	보조원	
1.개발여건 분석	①자연환경 ②인문환경 ③종합분석	30㎢ 30㎢ 30㎢	2.0 2.0 2.0	4.0 4.0 4.0	8.5 8.5 11.0	11.6 11.6 11.8	15.0 15.0 18.0	26.0 26.0 26.0	
	소 계		4.0	12.0	28.0	35.0	48.0	78.0	
2.기본구상	①개발방향설정 ②계획지표설정 ③토지이용체계 ④동선체계구상 ⑤유치시설종류 및 규모설정	30㎢ 30㎢ 30㎢ 30㎢ 30㎢	0.9 0.9 1.4 1.4 1.4	1.5 1.5 2.0 2.0 2.0	8.8 8.8 8.8 8.8 8.8	13.8 13.8 13.8 13.8 13.8	15.0 18.0 18.0 18.0 18.0	25.6 25.6 25.6 25.6 25.6	
	소 계		6.0	9.0	44.0	69.0	87.0	128.0	
3.기본계획 (부문별)	①공원용도지구계획 ②공원보전계획 ③공원시설계획 ④공원관리계획	30㎢ 30㎢ 30㎢ 30㎢	2.0 2.0 5.0 2.0	3.0 3.0 8.0 3.0	12.6 12.6 27.2 12.6	13.6 13.6 34.2 13.6	24.0 24.0 48.0 24.0	29.6 29.7 67.7 38.0	
	소 계		11.0	17.0	65.0	75.0	120.0	165.	
4.사업계획	①개발추진계획 ②관리운영계획	30㎢ 30㎢	4.6 3.4	6.9 5.1	20.0 14.0	21.0 19.0	15.0 15.0	20.5 16.5	
	소 계		8.0	12.0	34.0	40.0	30.0	37.0	
5.성과품 작성	①보고서작성 및 편집 ②관련도서작성	30㎢ 30㎢	1.6 0.4	1.6 0.4	5.0 2.0	7.2 4.8	6.0 9.0	4.0 11.0	
	소 계		2.0	2.0	7.0	12.0	15.0	15.0	
총 계			33.0	52.0	178.0	231.0	300.0	423.0	
6.기술협의	①공청회/주민설명회 ②주민간담회/시민계획단 ③위원회심의 지원 ④관계기관 협의	1식 1식 1식 1식	2.0 2.0 2.0 2.0	2.0 2.0 2.0 2.0	2.0 2.0 2.0 2.0	4.0 4.0 4.0 4.0	4.0 4.0 4.0 4.0	4.0 4.0 4.0 4.0	
	소 계		8.0	8.0	8.0	16.0	16.0	16.0	

주 : ①기술협의는 2회 이내 기준이며, 횟수가 늘어날 경우 증가배수에 해당하는 작업품과 비용을 가산한다. (필요항목 선택적 적용)

②각종영향성검토 및 각종영향평가업무는 별도의 엔지니어링활동업무로 계상한다.

3) 군립공원(5㎢ 기준)

(단위 : 인 · 일/표준단위)

구 분	업무내용	표준단위	소요인력						비고
			기술사	특급	고 급	중 급	초 급	보조원	
1.개발여건 분석	①자연환경	5㎢	1.0	1.3	3.7	5.0	6.3	10.3	
	②인문환경	5㎢	1.0	1.3	3.7	5.0	6.3	10.3	
	③종합분석	5㎢	1.0	1.4	4.6	5.0	7.4	10.4	
	소 계		3.0	4.0	12.0	15.0	20.0	31.0	
2.기본구상	①개발방향설정	5㎢	0.4	0.6	3.6	5.6	6.2	10.4	
	②계획지표설정	5㎢	0.5	0.7	3.6	5.6	7.2	10.4	
	③토지이용체계	5㎢	0.7	0.9	3.6	5.6	7.2	10.4	
	④동선체계구상	5㎢	0.7	0.9	3.6	5.6	7.2	10.4	
	⑤유치시설종류 및 규모 설정	5㎢	0.7	0.9	3.6	5.6	7.2	10.4	
	소 계		3.0	4.0	18.0	28.0	35.0	52.0	
3.기본계획 (부문별)	①공원용도지구계획	5㎢	0.8	1.2	5.1	5.5	9.6	12.0	
	②공원보전계획	5㎢	0.8	1.2	5.1	5.5	9.6	12.0	
	③공원시설계획	5㎢	1.7	3.3	10.7	13.5	19.2	27.5	
	④공원관리계획	5㎢	0.7	1.3	5.1	5.5	9.6	15.5	
	소 계		4.0	7.0	26.0	30.0	48.0	67.0	
4.사업계획	①개발추진계획	5㎢	1.7	2.8	8.0	9.0	6.5	8.9	
	②관리운영계획	5㎢	1.3	2.2	6.0	8.0	6.5	7.1	
	소 계		3.0	5.0	14.0	17.0	13.0	16.0	
5.성과품 작성	①보고서작성 및 편집	5㎢	0.8	0.8	2.2	3.0	2.8	1.7	
	②관련도서작성	5㎢	0.2	0.2	0.8	2.0	4.2	5.3	
	소 계		1.0	1.0	3.0	5.0	7.0	7.0	
총 계			14.0	21.0	73.0	95.0	123.0	173.0	
6.기술협의	①공청회/주민설명회	1식	2.0	2.0	2.0	4.0	4.0	4.0	
	②주민간담회/시민계획단	1식	2.0	2.0	2.0	4.0	4.0	4.0	
	③위원회심의 지원	1식	2.0	2.0	2.0	4.0	4.0	4.0	
	④관계기관 협의	1식	2.0	2.0	2.0	4.0	4.0	4.0	
	소 계		8.0	8.0	8.0	16.0	16.0	16.0	

주 : ①기술협의는 2회 이내 기준이며, 횟수가 늘어날 경우 증가배수에 해당하는 작업품과 비용을 가산한다. (필요항목 선택적 적용)

②각종영향성검토 및 각종영향평가업무는 별도의 엔지니어링활동업무로 계상한다.

2. 도시공원

1) 소공원, 어린이공원 (0.25만㎡ 기준)

(단위 : 인 · 일/표준단위)

구 분	업무내용	표준단위	소요인력						비고
			기술사	특급	고 급	중 급	초 급	보조원	
1.개발여건 분석	①자연환경	0.25만㎡	-	-	0.16	0.35	0.33	0.70	
	②인문환경	0.25만㎡	-	-	0.16	0.30	0.33	0.62	
	③종합분석	0.25만㎡	-	-	0.18	0.35	0.34	0.68	
	소 계		-	-	0.50	1.00	1.00	2.00	
2.기본구상	①개발방향설정	0.25만㎡	0.08	0.08	0.08	0.09	0.09	0.18	
	②계획지표설정	0.25만㎡	0.13	0.13	0.08	0.12	0.12	0.19	
	③토지이용체계	0.25만㎡	0.13	0.13	0.12	0.11	0.11	0.21	
	④동선체계구상	0.25만㎡	0.08	0.08	0.12	0.09	0.09	0.21	
	⑤유치시설종류 및 규모 설정	0.25만㎡	0.08	0.08	0.10	0.09	0.09	0.21	
	소 계		0.50	0.50	0.50	0.50	0.50	1.00	
3.기본계획 (부문별)	①토지이용계획	0.25만㎡	0.09	0.09	0.12	0.11	0.17	0.25	
	②교통동선계획	0.25만㎡	0.09	0.09	0.08	0.09	0.17	0.25	
	③시설물배치계획	0.25만㎡	0.09	0.09	0.10	0.10	0.19	0.50	
	④식재계획	0.25만㎡	0.14	0.14	0.12	0.11	0.28	0.75	
	⑤공급처리시설계획	0.25만㎡	0.09	0.09	0.08	0.09	0.19	0.25	
	소 계		0.50	0.50	0.50	0.50	1.00	2.00	
4.사업계획	①개발추진계획	0.25만㎡	-	-	0.30	0.27	0.27	0.54	
	②관리운영계획	0.25만㎡	-	-	0.20	0.23	0.23	0.46	
	소 계		-	-	0.50	0.50	0.50	1.00	
5.성과품 작성	①보고서작성 및 편집	0.25만㎡	-	-	-	0.33	0.60	0.80	
	②관련도서작성	0.25만㎡	-	-	-	0.17	0.40	1.20	
	소 계		-	-	-	0.50	1.00	2.00	
총 계			1.00	1.00	2.00	3.00	4.00	8.00	
6.기술협의	①공청회/주민설명회	1식	2.0	2.0	2.0	4.0	4.0	4.0	
	②주민간담회/시민계획단	1식	2.0	2.0	2.0	4.0	4.0	4.0	
	③위원회심의 지원	1식	2.0	2.0	2.0	4.0	4.0	4.0	
	④관계기관 협의	1식	2.0	2.0	2.0	4.0	4.0	4.0	
	소 계		8.0	8.0	8.0	16.0	16.0	16.0	

주 : ①기술협의는 2회 이내 기준이며, 횟수가 늘어날 경우 증가배수에 해당하는 작업품과 비용을 가산한다. (필요항목 선택적 적용)

②성격이 다른 공원인 근린공원, 주제공원 등과는 상호 구분하여 산정 합산하며, 각 개소의 공원별로 구분 산정함을 원칙으로 함.

2) 근린공원, 주제공원, 공원리모델링, 지역테마길(10만㎡ 기준)

(단위 : 인 · 일/표준단위)

구 분	업무내용	표준단위	소요인력						비고
			기술사	특급	고 급	중 급	초 급	보조원	
1.개발여건 분석	①자연환경	10만㎡	1.0	2.0	4.3	6.6	6.0	7.8	
	②인문환경	10만㎡	1.0	2.0	4.3	6.6	6.0	6.4	
	③종합분석	10만㎡	1.0	2.0	5.4	6.8	6.0	7.8	
	소 계		3.0	6.0	14.0	20.0	18.0	22.0	
2.기본구상	①개발방향설정	10만㎡	0.5	0.7	4.2	5.6	6.1	8.0	
	②계획지표설정	10만㎡	0.7	1.4	4.2	6.6	6.1	8.0	
	③토지이용체계	10만㎡	0.7	1.4	5.2	6.6	7.6	8.0	
	④동선체계구상	10만㎡	0.5	0.7	5.2	5.6	7.6	8.0	
	⑤유치시설종류 및 규모 설정	10만㎡	0.6	0.8	4.2	5.6	7.6	8.0	
	소 계		3.0	5.0	23.0	30.0	35.0	40.0	
3.기본계획 (부문별)	①토지이용계획	10만㎡	1.0	1.5	7.0	8.8	7.2	12.6	
	②교통동선계획	10만㎡	1.0	1.5	5.0	6.8	7.2	12.6	
	③시설물배치계획	10만㎡	1.0	1.5	5.0	6.8	7.2	12.6	
	④식재계획	10만㎡	2.0	2.0	7.0	8.8	11.2	12.6	
	⑤공급처리시설계획	10만㎡	1.0	1.5	5.0	6.8	7.2	12.6	
	소 계		6.0	8.0	29.0	38.0	40.0	63.0	
4.사업계획	①개발추진계획	10만㎡	2.2	2.8	10.2	9.0	12.0	12.2	
	②관리운영계획	10만㎡	1.8	2.2	6.8	8.0	11.0	10.8	
	소 계		4.0	5.0	17.0	17.0	23.0	23.0	
5.성과품 작성	①보고서작성 및 편집	10만㎡	0.8	0.8	2.0	4.0	3.6	5.0	
	②관련도서작성	10만㎡	0.2	0.2	1.0	2.0	2.4	5.0	
	소 계		1.0	1.0	3.0	6.0	6.0	10.0	
총 계			17.0	25.0	86.0	111.0	122.0	158.0	
6.기술협의	①공청회/주민설명회	1식	2.0	2.0	2.0	4.0	4.0	4.0	
	②주민간담회/시민계획단	1식	2.0	2.0	2.0	4.0	4.0	4.0	
	③위원회심의 지원	1식	2.0	2.0	2.0	4.0	4.0	4.0	
	④관계기관 협의	1식	2.0	2.0	2.0	4.0	4.0	4.0	
	소 계		8.0	8.0	8.0	16.0	16.0	16.0	

주 : ①기술협의는 2회 이내 기준이며, 횟수가 늘어날 경우 증가배수에 해당하는 작업품과 비용을 가산한다. (필요항목 선택적 적용)

②성격이 다른 공원인 근린공원, 주제공원 등과는 상호 구분하여 산정 합산하며, 각 개소의 공원별로 구분 산정함을 원칙으로 함.

③공원리모델링은 기존공원에 대한 유지, 보수, 개수 등 공원기능을 재향상시키는 계획임.

④지역테마길은 '둘레길' 등과 같은 특정테마의 길, 옛거리, 폐도, 폐철도 등을 활용한 휴식, 산책, 공원 등의 기능을 제고하는 길관련 사업을 말함.

3) 도시자연공원구역 (30만㎡ 기준)

(단위 : 인 · 일/표준단위)

구 분	업무내용	표준단위	소요인력(인·일)						비고
			기술사	특급	고 급	중 급	초 급	보조원	
1.개발여건 분석	①자연환경	30만㎡	1.0	1.3	3.7	5.0	6.3	10.3	
	②인문환경	30만㎡	1.0	1.3	3.7	5.0	6.3	10.3	
	③종합분석	30만㎡	1.0	1.4	4.6	5.0	7.4	10.4	
	소 계		3.0	4.0	12.0	15.0	20.0	31.0	
2.기본구상	①개발방향설정	30만㎡	0.4	0.6	3.6	5.6	6.2	10.4	
	②계획지표설정	30만㎡	0.5	0.7	3.6	5.6	7.2	10.4	
	③토지이용체계	30만㎡	0.7	0.9	3.6	5.6	7.2	10.4	
	④동선체계구상	30만㎡	0.7	0.9	3.6	5.6	7.2	10.4	
	⑤유치시설종류 및 규모 설정	30만㎡	0.7	0.9	3.6	5.6	7.2	10.4	
	소 계		3.0	4.0	18.0	28.0	35.0	52.0	
3.기본계획 (부문별)	①토지이용계획	30만㎡	1.0	1.5	5.2	6.2	9.6	12.0	
	②교통동선계획	30만㎡	0.5	1.2	5.0	5.5	9.6	12.0	
	③시설물배치계획	30만㎡	1.0	1.5	5.2	6.2	9.6	15.5	
	④식재계획	30만㎡	1.0	1.6	5.6	6.6	9.6	15.0	
	⑤공급처리시설계획	30만㎡	0.5	1.2	5.0	5.5	9.6	12.0	
	소 계		4.0	7.0	26.0	30.0	48.0	67.0	
4.사업계획	①개발추진계획	30만㎡	1.7	2.8	8.0	9.0	6.5	8.9	
	②관리운영계획	30만㎡	1.3	2.2	6.0	8.0	6.5	7.1	
	소 계		3.0	5.0	14.0	17.0	13.0	16.0	
5.성과품 작성	①보고서작성 및 편집	30만㎡	0.8	0.8	2.2	3.0	2.8	1.7	
	②관련도서작성	30만㎡	0.2	0.2	0.8	2.0	4.2	5.3	
	소 계		1.0	1.0	3.0	5.0	7.0	7.0	
총 계			14.0	21.0	73.0	95.0	123.0	173.0	
6.기술협의	①공청회/주민설명회	1식	2.0	2.0	2.0	4.0	4.0	4.0	
	②주민간담회/시민계획단	1식	2.0	2.0	2.0	4.0	4.0	4.0	
	③위원회심의 지원	1식	2.0	2.0	2.0	4.0	4.0	4.0	
	④관계기관 협의	1식	2.0	2.0	2.0	4.0	4.0	4.0	
	소 계		8.0	8.0	8.0	16.0	16.0	16.0	

주 : ①기술협의는 2회 이내 기준이며, 횟수가 늘어날 경우 증가배수에 해당하는 작업품과 비용을 가산한다. (필요항목 선택적 적용)

②각종영향성검토 및 각종영향평가업무는 별도의 엔지니어링활동업무로 계상한다.

3-5-2 조사측량

○ 측량품을 별도 적용한다.

3-5-3 토질조사 및 시험

○ 토질조사 및 시험품을 별도 적용한다.

3-5-4 기본 설계 및 실시설계

○ 기본설계 및 실시설계의 산출기준은 엔지니어링사업대가의 기준 중 건설부문 공사비 요율을 적용한다.

3-6 주요업무내용

3-6-1 자연공원

구 분	업무내용	내 용
1.개발여건분석	①자연환경	·수계, 토양 및 지질, 지형, 지세 등의 조사 ·기온, 강수량, 풍향, 풍속, 천기일수 등의 조사 ·기타 식생 등 생태조사, 경관조사
	②인문환경	·배후지의 탐방객변화, 소득수준변화 ·관련법규 및 계획검토 ·관광환경자원조사 ·용도지구현황, 교통시설, 기반시설 조사 ·역사성 등 지역성격 조사
	③종합분석	·제반현황의 종합적 분석 ·개발잠재력 및 문제점 검토
2.기본구상	①개발방향설정	·개발잠재력에 의한 개발방향 설정
	②계획지표설정	·탐방객 지표설정 ·탐방객의 구성, 규모설정정
	③토지이용체계구상	·공원구역의 타당성 검토 ·공간구성체계설정 ·용도지구구상안 작성
	④동선체계구상	·이용자의 공원 이용체계구상 ·용도지구에 따른 기능별 동선구상
	⑤유치시설종류 및 규모설정	·적정수용능력판단 ·공원시설 종류 및 규모설정
3.기본계획 (부문별)	①공원용도지구계획	·계획의 기본방향 ·용도지구계획
	②공원보전계획	·공원구역 및 공원보호구역의 보전계획 ·용도지구별 세부 보전계획 ·자연환경에 미치는 평가 등의 반영 ·문화재, 보호물 등의 보존계획
	③공원시설계획	·용도지구별 시설계획 ·집단시설지구계획 ·교통량 수요추정 ·도로망체계 설정 및 구상안 작성. 등산로 계획
	④공원관리계획	·용도지구별 관리·운영계획 ·공원보호구역 관리계획
4.사업계획	①개발추진계획	·개발추진방안 ·사업투자계획
	②관리운영계획	·공원관리계획 ·공원운영계획

3-6-2 도시공원

구 분	업무내용	내 용
1.개발여건분석	①자연환경	·수계, 토양 및 지질, 지형, 지세 등의 조사 ·기온, 강수량, 풍향, 풍속, 천기일수 등의 조사 ·기타 식생 등 경관조사
	②인문환경조사	·배후지의 인구변화 ·관련법규 및 계획검토 ·토지이용현황, 교통시설, 기반시설 조사 ·역사성 등 지역성격 조사
	③종합분석	·제반현황의 종합적 분석 ·개발잠재력 및 문제점 검토
2.기본구상	①개발방향설정	·개발잠재력에 의한 개발방향 설정
	②계획지표설정	·인구지표설정 ·이용인구의 구성, 규모설정
	③토지이용체계구상	·공간구성체계 설정 ·토지이용구상안 작성
	④동선체계구상	·이용자의 공원 이용체계구상 ·토지이용에 따른 기능별 동선구상
	⑤유치시설종류 및 규모설정	·적정수용능력판단 ·시설 종류 및 규모설정
3.기본계획 (부문별)	①토지이용계획	·공간구성체계설정 ·토지이용종합계획수립
	②교통동선계획	·교통량수요추정 ·가도로망체계설정 ·가도로망 구상안 작성 ·간선 가로망계획 ·세가로망계획
	③시설물배치계획	·주요시설물의 배치계획
	④식재계획	·식재계획
	⑤공급처리시설계획	·상하수도, 전기통신 부문에 대한 용량 추정 및 공급처리방안
4.사업계획	①개발추진계획	·개략공사비 산정 ·공종별, 재원별 투자계획 ·단계별, 연차별 투자계획
	②관리운영계획	·환경보전방안 제시 ·관리체계 및 대책 제시 ·운영방안 제시

3-7 표준성과품

1. 자연공원(기본계획)

성과구분	표 준 성 과 도 서			비 고
	구 분	규 격	제출부수	
현황도	·위치도 ·현황종합분석도	1/50,000~1/25,000 1/50,000~1/5,000	1부 〃	
계획도	·종합기본계획도 ·용도지구계획도 ·교통동선계획도 ·시설계획도 ·집단시설계획도	1/5,000~1/3,000 〃 〃 〃 〃	〃 〃 〃 〃 〃	조경, 건축
보고서	·보고서 ·계획 관련도서	발주자와 협의 결정	발주자와 협의결정	

주 : ①제출부수 및 성과품 종류가 증가할 경우에는 증가배수에 해당하는 작업품과 비용을 가산한다.
②계획보고서, 기타 관련자료의 규격 및 제출부수는 발주자와의 협의에 의하여 비용 산출하여 산정한다.

2. 도시공원(기본계획)

성과구분	표 준 성 과 도 서			비 고
	구 분	규 격	제출부수	
현황도	·위치도 ·현황종합분석도	1/50,000~1/25,000 1/50,000~1/5,000	1부 〃	
계획도	·종합기본계획도 ·토지이용계획도 ·교통동선계획도 ·시설물배치계획도 ·식재계획도 ·공급처리시설계획도	1/5,000~1/3,000 〃 〃 〃 〃 〃	〃 〃 〃 〃 〃 〃	조경,건축
보고서	·보고서 ·계획 관련도서	발주자와 협의 결정	발주자와 협의결정	

주 : ①제출부수 및 성과품 종류가 증가할 경우에는 증가배수에 해당하는 작업품과 비용을 가산한다.
②계획보고서, 기타 관련자료의 규격 및 제출부수는 발주자와의 협의에 의하여 비용 산출하여 산정한다.

제4절 관광지·유원지·휴양지·체육시설지 계획

4-1 정 의

○ 관광지 및 관광단지의 계획은 관광진흥법에 의하여 관광객의 휴양, 보양, 운동, 오락, 문화, 경관 등의 욕구를 충족시키기 위하여 자연자원, 문화자원, 사회자원, 산업자원을 보존 개발하며 관광객의 편의를 위한 인공적 시설의 설치 등에 관한 계획 을 말하며 레저단지, 리조트, 휴양단지, 휴양레저단지, 관광어촌 등에 관한 계획을 포함한다.

○ 유원지계획은 국토의 계획 및 이용에 관한 법률에 의하여, 주민의 복지향상에 기여하기 위하여 도시계획으로 설치하는 오락과 휴양시설의 설치 등에 관한 계획을 말한다.

○ 자연공원법상의 공원마을지구의 계획은 공원이용객 편익 및 공원보호관리를 위해 적합한 공원시설 등 설치 등에 관한 계획을 말한다.

○ 산림문화휴양시설 계획은 산림과 인간의 상호작용으로 형성되는 총체적 생활양식과 산림 안에서 이루어지는 심신의 휴식 및 치유 등을 할 수 있도록 조성한 산림문화, 휴양에 관한 법률상의 제 시설(자연휴양림, 산림욕장, 치유의 숲, 숲길 등) 및 이와 유사한 시설계획을 말한다.

○ 도시숲 조성계획이라 함은 산림자원의 조성 및 관리에 관한 법률에 따라 국민의 건강증진, 정서 함양 및 체험 활동 등을 위한 조성계획을 말한다.

○ 생태숲 조성계획은 산림생태계의 안정과 산림생물의 다양성을 유지・증진하고 연구・교육・탐방・체험 등을 위하여 산림보호법에 따라 필요한 산림을 지정하여 보전·관리하고 이용에 필요한 시설을 조성하기 위한 계획을 말한다.

○ 수목원 계획은 수목원 조성 및 진흥에 관한 법률에 의한 시설 계획을 말한다.

○ 수렵장 계획은 야생생물보호 및 관리에 관한 법률에 의한 시설 계획을 말한다.

○ 농어촌휴양지의 계획은 농어촌지역안의 자연경관을 보전하며 농어촌 소득증대에 기여하기 위하여 농어촌정비법에 의해 지정·조성되는 제 시설의 계획을 말한다.

○ 체육시설지의 계획이라 함은 체육시설의 설치·이용에 관한 법률에 의한 야외활동시설 혹은 2개 이상의 복합시설(이하 시설단지라 한다)과 도시·군계획시설의 결정·구조 및 설치기준에 관한 규칙의 운동장, 체육시설 등의 사업에 대한 제 계획을 말한다. 체육시설지 성격이 단독 활동적 시설임을 감안하여 이용자의 편의, 휴양 등 정적시설 등이 복합적으로 고려되어 계획, 설계되어야 한다.

- 체육시설의 설치·이용에 관한 법률에 의한 시설 : 골프장, 스키장, 경마장, 요트 및 카누 등의 수상스포츠시설
- 2개 이상의 복합시설(시설단지) : 육상경기, 축구, 야구, 농구, 궁도, 정구, 사격, 수영, 빙상경기, 골프연습장 등의 시설 및 부대시설이 2개 또는 그 이상의 설치가 필요한

지구(공원은 체육공원 품 적용)

- 운동장·체육시설 : 종합운동장, 체육시설의설치·이용에관한법률상의 체육시설

○ 청소년활동시설 계획이라 함은 청소년활동진흥법에 의한 청소년의 균형있는 성장을 위하여 필요한 활동과 이러한 활동을 소재로 하는 수련활동시설·교류활동시설·문화활동시설 등 다양한 형태의 활동시설들의 복합적인 시설계획을 말한다.

○ 온천지계획은 온천법에 의하여 이용객의 건강·휴양 등을 위한 온천시설 계획을 말한다.

○ 노인휴양촌 계획이라 함은 노인복지법에 의한 노인여가의 효율적인 수용을 목적으로 노인들의 건강증진과 복지향상에 기여할 수 있도록 일정한 지역에 휴양시설, 의료시설, 관광, 레크레이션 시설을 종합적으로 개발하는 시설계획을 말한다.

○ 장사시설계획이라 함은 장사등에 관한 법률에 의한 계획을 말한다.

○ 야영장 계획이라 함은 주변자연경관이 수려한 지역에서 이용객의 레저 및 휴양등을 위한 시설계획을 말한다.

○ 문화시설계획은 도시 · 군계획시설의 결정 · 구조 및 설치기준에 관한 규칙에 의하여 문화발전 및 문화증진을 위하여 지역의 특성과 기능을 고려한 시설계획을 말한다.

○ 정원계획이라 함은 개별 또는 관계법령에 따라 조경수 및 시설 등을 활용한 조경공간 계획을 말한다.

4-2 자료제공의 전제

○ 당해 계획의 수립에 필요한 모든 관련 자료는 원칙적으로 발주자가 제공하는 것으로 하되, 발주자가 보유하지 않는 자료는 엔지니어링사업자가 수집한다.

○ 발주자가 제공하지 못하는 자료의 조사에 있어서는 그 규모·내용에 의거하여 별도의 엔지니어링사업대가를 산정하여 엔지니어링사업자가 수행하며, 관련 자료의 기밀성과 광범위한 자료가 필요한 경우 조사·분석에 필요한 상당기간과 자료조사비용이 전제되어야한다.

4-3 업무범위와 추진과정

4-3-1 업무범위

○ 관광(단)지, 유원지, 공원마을지구, 산림문화휴양시설, 생태숲, 도시숲, 수목원, 수렵장, 농어촌휴양지, 체육시설지, 청소년활동시설, 온천지, 노인휴양촌, 장사시설, 야영장(캠핑장 등), 문화시설, 정원 계획은 기본계획, 기본설계, 실시설계를 주요업무내용으로 한다.

○ 인허가 과정에서 별도 승인을 받아야 하는 2가지 이상의 업무가 복합적으로 수행될 때에는 발주자와 협의과정을 거쳐 별도의 엔지니어링활동업무로 산정한다.

구 분	내 용	별도비용 산정
·관광(단)지	관광진흥법에 의한 조성계획 승인 또는 수립	관광지 기본계획 엔지니어링 사업대가 별도산정
·유원지	국토의 계획 및 이용에 관한 법률에 의한 조성계획 승인 또는 수립	
·공원마을지구	자연공원법에 의한 공원계획 승인 또는 수립	도시·군 관리계획(변경) 엔지니어링 사업대가 별도산정
·산림문화·휴양시설	산림문화·휴양에 관한 법률에 의한 조성계획 승인 또는 수립	
·생태숲	산림보호법에 의한 생태숲 지정 또는 사업승인	
·도시숲	산림자원의 조성 및 관리에 관한 법률에 의한 도시림등의 조성·관리계획 승인	
·수목원	수목원 조성 및 진흥에 관한 법률에 의한 조성계획 승인 또는 수립	
·수렵장	야생생물보호 및 관리에 관한 법률에 의한 설정 승인 또는 수립	
·농어촌휴양지	농어촌정비법에 의한 개발계획 승인 또는 수립	
·체육시설지	체육시설의 설치·이용에 관한 법률에 의한 사업계획 승인 또는 수립	
·청소년활동시설	청소년활동진흥법 의한 조성계획 승인 또는 수립	
·온천지	온천법에 의한 개발계획 승인 또는 수립	
·노인휴양촌	노인복지법에 의한 법인설립인가	
·장사시설	장사등에 관한 법률에 의한 조성계획 승인 또는 수립	
·야영장(캠핑장 등)	관광진흥법/농어촌정비법/청소년활동진흥법 등에 의한 기본계획 수립	
·문화시설	도시・군계획시설의 결정・구조 및 설치기준에 관한 규칙에 의한 시설계획 수립	
·정원	기타 법령에 따라 조성되는 조경수를 활용한 조경공간 계획	

4-3-2 추진과정

○ 타 부처(관계기관)와의 협의나 전문가 자문 등에 소요되는 기간은 과업수행기간에서 제외하여 그 소요기간만큼 과업수행기간을 연장하여야 한다.

관광지 등의 계획 업무추진과정

4-4 품 산정의 원단위 산정과 기준

4-4-1 표준품 산정내역

○ 표준품 산정의 기준이 되는 비목은 제1장 총칙에서 제시한 비목을 중심으로 하였으며, 관광지 등의 계획수립에 필요한 사항만을 대상으로 한다.

○ 표준품 산정의 기본이 되는 직접인건비 품의 작업항목별 보할은 기존의 경험적 내용 및 업무의 난이도를 감안하여 설정토록 한다.

1. 조사 및 측량, 토질조사 및 시험

○ 측량, 토질조사, 토지적성평가, 문화재지표조사 등의 품은 별도 적용한다.

2. 기본계획

종 별		내 용	세부항목	단 위	비 고
직접비	직접인건비	1.개발여건분석	①자연환경 ②인문환경 ③종합분석	인·일 〃 〃	
		2.기본구상	①개발방향설정 ②계획지표설정 ③토지이용체계구상 ④동선체계구상 ⑤유치시설종류 및 규모설정	〃 〃 〃 〃 〃	
		3.기본계획 (부문별)	①토지이용계획 ②교통동선계획 ③시설물배치계획 ④식재계획 ⑤공급처리시설계획	〃 〃 〃 〃 〃	
		4.사업계획	①사업투자계획 ②관리운영계획	〃 〃	
		5.성과품 작성	①보고서작성 및 편집 ②관련도서작성	〃 〃	
		6.기술협의	①공청회 / 주민설명회 ②주민간담회 / 시민계획단 ③위원회 심의 지원 ④관계기관 협의	〃 〃 〃 〃	
	직접경비	여비, 인쇄비, 조감도, 회의준비비, 현장운영비 등		식	제1장 총칙참조
간접비	제경비	(직접인건비)×120%		〃	〃
	기술료	(직접인건비+제경비)×30%		〃	〃

주 : 관광지 등의 계획과 관련되는 부수적인 업무인 조사, 측량, 토질조사 및 시험, 환경영향평가, 교통영향분석 개선대책, 사전재해영향성검토, 경제적 타당성분석, 도시·군관리계획에 의한 추가계획 등은 별도의 엔지니어링활동업무로 간주한다.

3. 기본설계, 실시설계의 표준산정내역

○ 기본설계와 실시설계의 품 산정은 엔지니어링사업대가의 기준 중 건설부문 공사비요율을 적용한다.

4-4-2 책정기준

1. 계획·기준면적의 설정

○ 기준면적의 원단위 설정을 위해 이미 지정된 관광지, 유원지의 등의 면적 분포 현황을 분석한 결과 빈도가 가장 높은 것을 기준면적으로 산정 하였다.

·관광(단)지, 유원지, 공원마을지구, 체육시설지, 온천지	20만㎡
·농·어촌휴양지, 청소년활동시설, 노인휴양촌, 산림문화휴양시설, 생태숲, 도시숲, 수목원, 수렵장, 야영장, 장사시설, 문화시설, 정원	10만㎡

○ 계획면적은 고시된 경우 법정계획면적을, 신설된 경우는 기본구상을 전제로 한 조사면적을 기준으로 하되, 다음의 경우에는 계획면적에 포함시킨다.

- 강, 바다 등을 포함하는 지역은 강, 바다 등이 시설지구로 이용될 때 기준면적에 포함함을 원칙으로 한다.

2. 표준품의 산정방법

○ 표준품의 적용에 있어 기준면적과 계획면적의 차이에 따른 품 산정은 아래의 수정식에 따라 기준면적의 소요작업량을 수정하여 품 산정한다.

○ 소요작업량 = 기준면적소요작업량 × 면적보정계수(α) × 입지보정계수(β)

3. 계획안의 수정과 과업중지에 따른 산정방법

○ 계획안이 작성되고 주민공람, 의회보고 등 행정절차과정을 거쳐 계획안이 확정된 후 발주자의 사정에 의하여 계획안이 일부변경·재작업이 수행되는 경우에는 그 변경·재작업의 정도에 따라 엔지니어링사업대가의 50～100% 수준에서 비용을 추가 지급하여야 한다.

○ 과업수행 중 발주자의 사정에 따른 과업 중단으로 인해 정부 회계연도가 경과되어 현저한 비용의 차이가 발생하였을 경우에는 엔지니어링사업대가를 당해 신년도의 노임단가를 기준으로 재산정하여야 한다.

4-4-3 단위별 변화수정과 보정

1. 작업량 보정계수 산정

1) 면적의 대소에 대한 작업량 보정계수 산정

○ 표준품의 적용에 있어 계획면적이 기준면적을 초과하거나 못 미치는 경우의 직접인력 소요작업량의 산정을 위한 면적보정계수(α)는 다음의 식에 의해 산정한다.

○ 관광(단)지, 유원지, 공원마을지구, 체육시설지, 온천지

$$\alpha = \left(\frac{\text{계획면적}}{\text{기준면적}}\right)^{0.6} = \left(\frac{A}{20}\right)^{0.6}$$

α : 보정계수
A : 계획면적(만㎡)

계획면적에 대한 보정계수(관광지, 유원지 등)

계획면적(A, 만㎡)	보정계수(α)	계획면적(A, 만㎡)	보정계수(α)
10	0.660	23	1.087
11	0.699	24	1.116
12	0.736	25	1.143
13	0.772	30	1.275
14	0.807	35	1.399
15	0.841	40	1.516
16	0.875	45	1.627
17	0.907	50	1.733
18	0.939	60	1.933
19	0.970	70	2.121
20	1.000	80	2.297
21	1.030	90	2.466
22	1.059	100	2.627

※계획면적이 10만㎡ 미만의 경우 보정계수는 10만㎡를 적용한다.

○ 농어촌휴양지, 청소년활동시설, 노인휴양촌, 산림문화휴양시설, 생태숲, 도시숲, 수목원, 수렵장, 야영장, 장사시설, 문화시설, 정원

$$\alpha = \left(\frac{\text{계획면적}}{\text{기준면적}}\right)^{0.6} = \left(\frac{A}{10}\right)^{0.6}$$

α : 보정계수
A : 계획면적(만㎡)

계획면적에 대한 보정계수(농어촌휴양지, 청소년활동시설 등)

면적(A) 만㎡	보정계수 (α)	면적(A) 만㎡	보정계수 (α)	면적(A) 만㎡	보정계수 (α)
2	0.399	13	1.161	24	1.647
3	0.503	14	1.211	25	1.685
4	0.593	15	1.260	26	1.723
5	0.673	16	1.307	27	1.761
6	0.747	17	1.353	28	1.798
7	0.816	18	1.397	29	1.834
8	0.880	19	1.441	30	1.870
9	0.941	20	1.484	35	2.042
10	1.000	21	1.526	40	2.203
11	1.055	22	1.567	45	2.356
12	1.109	23	1.607	50	2.502

※농어촌휴양지, 청소년활동시설 등 계획면적이 2만㎡ 미만이면 보정계수는 2만㎡에 준한다.
※50만㎡를 초과하는 경우 관광지품을 적용한다.

2) 지형과 입지에 따른 보정계수

구 분	입지에 따른 보정계수(β)
내륙형 평지	1.0
내륙형 구릉지	1.2 ~ 1.4
내륙형 산지	1.2 ~ 1.5
도시형 평지/구릉지	1.2 ~ 1.4
도시형 산지	1.3 ~ 1.5
해안·호소형 평지/구릉지/산지	1.3 ~ 1.5

2. 직접인건비 소요 작업량 산정

○ 계획면적의 대소에 따른 직접인력 소요작업량의 산정방법은 아래와 같이 기준면적의 직능별 직접인력 소요작업량에 계획단위 보정계수(α, β)를 곱하여 산출한다.

구 분	기준면적 (만㎡)	총작업량(인·일)					
		기술사	특 급	고 급	중 급	초 급	보조원
관광지 등	20	17.0αβ	25.0αβ	93.0αβ	111.0αβ	157.0αβ	192.0αβ
농어촌휴양지 등	10	13.0αβ	19.0αβ	70.0αβ	84.0αβ	117.0αβ	145.0αβ

4-5 표준단위 업무분류와 원단위

4-5-1 기술업무의 직능별 직접인력 소요작업량

관광(단)지, 유원지, 공원마을지구, 체육시설지, 온천지 (20만㎡ 기준)

(단위 : 인 · 일/표준단위)

구 분	업무내용	표준단위	소요인력						비고
			기술사	특 급	고 급	중 급	초 급	보조원	
1.개발여건 분석	①자연환경	20만㎡	0.9	1.9	5.6	6.6	9.3	13.3	
	②인문환경	20만㎡	0.9	1.9	5.6	6.6	9.3	13.3	
	③종합분석	20만㎡	1.2	2.2	6.8	6.8	9.4	9.4	
	소 계		3.0	6.0	18.0	20.0	28.0	36.0	
2.기본구상	①개발방향설정	20만㎡	0.5	0.7	3.6	5.6	8.0	9.6	
	②계획지표설정	20만㎡	0.8	1.4	5.5	6.6	9.5	11.6	
	③토지이용체계구상	20만㎡	0.8	1.4	5.5	6.6	9.5	11.6	
	④동선체계구상	20만㎡	0.5	0.7	4.7	5.6	8.0	11.6	
	⑤유치시설종류 및 규모설정	20만㎡	0.4	0.8	4.7	5.6	8.0	11.6	
	소 계		3.0	5.0	24.0	30.0	43.0	56.0	
3.기본계획 (부문별)	①토지이용계획	20만㎡	1.0	1.5	6.5	8.8	14.0	15.4	
	②교통동선계획	20만㎡	1.0	1.5	5.5	6.8	11.0	13.4	
	③시설물배치계획	20만㎡	1.0	1.5	5.5	6.8	11.0	15.4	
	④식재계획	20만㎡	2.0	2.0	9.0	8.8	14.0	15.4	
	⑤공급처리시설계획	20만㎡	1.0	1.5	5.5	6.8	11.0	13.4	
	소 계		6.0	8.0	32.0	38.0	61.0	73.0	
4.사업계획	①사업투자계획	20만㎡	2.3	2.7	8.4	9.0	7.5	9.4	
	②관리운영계획	20만㎡	1.7	2.3	6.6	8.0	7.5	7.6	
	소 계		4.0	5.0	15.0	17.0	15.0	17.0	
5.성과품 작성	①보고서작성 및 편집	20만㎡	0.8	0.8	3.0	4.0	5.0	2.0	
	②관련도서작성	20만㎡	0.2	0.2	1.0	2.0	5.0	8.0	
	소 계		1.0	1.0	4.0	6.0	10.0	10.0	
총 계			17.0	25.0	93.0	111.0	157.0	192.0	
6.기술협의	①공청회/주민설명회	1식	2.0	2.0	2.0	4.0	4.0	4.0	
	②주민간담회/시민계획단	1식	2.0	2.0	2.0	4.0	4.0	4.0	
	③위원회심의 지원	1식	2.0	2.0	2.0	4.0	4.0	4.0	
	④관계기관 협의	1식	2.0	2.0	2.0	4.0	4.0	4.0	
	소 계		8.0	8.0	8.0	16.0	16.0	16.0	

주 : ①기술협의는 2회 이내 기준이며, 횟수가 늘어날 경우 증가배수에 해당하는 작업품과 비용을 가산한다. (필요항목 선택적 적용)

농어촌휴양지, 청소년활동시설, 노인휴양촌, 산림문화휴양시설, 생태숲, 도시숲, 수목원, 수렵장, 야영장, 장사시설, 문화시설, 정원 (10만㎡ 기준)

(단위 : 인·일/표준단위)

구 분	업무내용	표준단위	소요인력						비고
			기술사	특 급	고 급	중 급	초 급	보조원	
1.개발여건 분석	①자연환경	10만㎡	0.7	1.4	4.2	5.0	7.0	10.0	
	②인문환경	10만㎡	0.7	1.4	4.2	5.0	7.0	10.0	
	③종합분석	10만㎡	0.9	1.7	5.1	5.0	7.0	7.0	
	소 계		2.3	4.5	13.5	15.0	21.0	27.0	
2.기본구상	①개발방향설정	10만㎡	0.4	0.6	2.7	4.2	6.0	7.2	
	②계획지표설정	10만㎡	0.6	1.0	4.1	5.1	7.0	8.7	
	③토지이용체계구상	10만㎡	0.6	1.0	4.1	5.1	7.0	8.7	
	④동선체계구상	10만㎡	0.4	0.7	3.5	4.3	6.0	8.7	
	⑤유치시설종류 및 규모설정	10만㎡	0.3	0.7	3.6	4.3	6.0	8.7	
	소 계		2.3	4.0	18.0	23.0	32.0	42.0	
3.기본계획 (부문별)	①토지이용계획	10만㎡	0.8	1.1	4.9	6.6	10.5	11.6	
	②교통동선계획	10만㎡	0.8	1.1	4.1	5.1	8.3	10.0	
	③시설물배치계획	10만㎡	0.8	1.1	4.1	5.1	8.3	11.7	
	④식재계획	10만㎡	1.5	1.5	6.8	6.6	10.5	11.7	
	⑤공급처리시설계획	10만㎡	0.8	1.2	4.1	5.1	8.4	10.0	
	소 계		4.7	6.0	24.0	28.5	46.0	55.0	
4.사업계획	①사업투자계획	10만㎡	1.7	2.0	6.5	6.8	5.5	7.0	
	②관리운영계획	10만㎡	1.3	1.7	5.0	6.2	5.5	6.0	
	소 계		3.0	3.7	11.5	13.0	11.0	13.0	
5.성과품 작성	①보고서작성 및 편집	10만㎡	0.6	0.6	2.3	3.0	3.5	2.0	
	②관련도서작성	10만㎡	0.1	0.2	0.7	1.5	3.5	6.0	
	소 계		0.7	0.8	3.0	4.5	7.0	8.0	
총 계			13.0	19.0	70.0	84.0	117.0	145.0	
6.기술협의	①공청회/주민설명회	1식	2.0	2.0	2.0	4.0	4.0	4.0	
	②주민간담회/시민계획단	1식	2.0	2.0	2.0	4.0	4.0	4.0	
	③위원회심의 지원	1식	2.0	2.0	2.0	4.0	4.0	4.0	
	④관계기관 협의	1식	2.0	2.0	2.0	4.0	4.0	4.0	
	소 계		8.0	8.0	8.0	16.0	16.0	16.0	

주 : ①기술협의는 2회 이내 기준이며, 횟수가 늘어날 경우 증가배수에 해당하는 작업품과 비용을 가산한다. (필요항목 선택적 적용)

②산림문화휴양시설 등 계획수립외에 별도의 지정절차가 필요한 사업에 대하여 「개발여건분석」및 「기본구상」항목에서 당초투입인력을 기준으로 50%이내에서 추가로 계상한다.

4-5-2 조사측량

○ 측량품을 별도 적용한다.

4-5-3 토질조사 및 시험

○ 토질조사 및 시험품을 별도 적용한다.

4-5-4 기본설계 및 실시설계

○ 기본설계 및 실시설계의 산출기준은 엔지니어링사업대가의 기준 중 건설부문 공사비 요율을 적용한다.

4-6 주요업무내용

구 분	업무내용	내 용
1.개발여건분석	①자연환경조사	·수계, 토양 및 지질, 지형, 지세 등의 조사 ·기온, 강수량, 풍향, 풍속, 천기일수 등의 조사 ·기타 식생 등 생태조사, 경관조사
	②인문환경조사	·배후지의 탐방객변화, 소득수준변화 ·관련법규 및 계획검토 ·관광환경자원조사 ·용도지구현황, 교통시설, 기반시설 조사 ·역사성 등 지역성격 조사
	③종합분석	·제반현황의 종합적 분석 ·개발잠재력 및 문제점 검토
2.기본구상	①개발방향설정	·개발잠재력에 의한 개발방향설정
	②계획지표설정	·탐방객지표설정 ·탐방객의 구성, 규모설정
	③토지이용체계구상	·공간구성체계설정 ·용도지구구상안 작성
	④동선체계구상	·이용자의 공원 이용체계구상 ·용도지구에 따른 기능별 동선구상
	⑤유치시설종류 및 규모설정	·적정수용능력판단 ·시설 종류 및 규모설정
3.기본계획 (부문별)	①토지이용계획	·공간구성체계설정 ·토지이용종합계획수립
	②교통동선계획	·교통량수요추정 ·도로망체계설정 ·도로망 구상안 작성 ·간선가로망계획 ·세가로망계획
	③시설물배치계획	·주요시설물(건축·조경)의 배치계획 ·시설물의 형태, 규모, 형식 등의 개략적인 시설물 계획
	④식재계획	·식재계획
	⑤공급처리시설계획	·상하수도, 전기통신 부문에 대한 용량추정 및 공급처리방안
4.사업계획	①사업투자계획	·개략공사비산정 ·공종별, 재원별 투자계획 ·단계별, 년차별 투자계획
	②관리운영계획	·환경보전방안제시 ·관리체계 및 대책제시 ·운영방안제시

4-7 표준성과품

성과구분	표준성과도서			비 고
	구 분	규 격	제출부수	
현황도	·위치도 ·현황종합분석도	1/50,000～1/25,000 1/50,000～1/5,000	1부 〃	
계획도	·종합기본계획도 ·토지이용계획도 ·시설물배치계획도 ·교통동선계획 ·식재계획도 ·공급처리시설계획도	1/5,000～1/3,000 〃 〃 〃 〃 〃	〃 〃 〃 〃 〃 〃	조경, 건축
보고서	·계획보고서 ·계획관련도서	발주자와 협의결정	발주자와 협의결정	관리운영계획 사업계획 포함

주 : ①제출부수 및 성과품 종류가 증가할 경우에는 증가배수에 해당하는 작업품과 비용을 가산한다.
②계획보고서, 기타 관련 자료의 규격 및 제출부수는 발주자와의 협의에 의하여 비용 산출하여 산정한다.

제5절 문화재 사적지 계획

5-1 정 의

○ 문화재 및 사적지계획이란 인류문화의 발달을 나타내는 역사적 장소에 대하여 문화재 및 사적을 복원, 보존 또는 정비하거나 이를 활용함으로써 국민의 문화적 향상을 도모하고자 이에 관련되는 시설(사적공원(史蹟公園),이용시설 및 전시시설 등)을 계획, 설치하는 작업을 말한다.

5-2 자료제공의 전제

○ 문화재 및 사적지계획에 필요한 모든 관련자료(기본도면 및 지정고시 도면 등)는 원칙적으로 발주자가 제공하는 것으로 하되, 발주자가 보유하지 않는 자료는 엔지니어링사업자가 수집한다.

○ 발주자가 제공하지 못하는 자료의 조사에 있어서는 그 규모·내용에 의거하여 별도의 엔지니어링사업대가를 산정하여 엔지니어링사업자가 수행하며, 관련 자료의 기밀성과 광범위한 자료가 필요한 경우 조사·분석에 요구되는 상당기간과 자료수집비용이 전제되어야 한다.

5-3 업무범위와 추진과정

5-3-1 업무범위

○ 문화재 및 사적지계획의 업무범위는 기본계획, 기본설계, 실시설계 등을 주요 업무로 한다.

5-3-2 추진과정

○ 타 부처(관계기관)와의 협의나 전문가 자문 등에 소요되는 기간은 과업수행기간에서 제외하여 그 소요기간 만큼 과업수행기간을 연장하여야 한다.

문화재·사적지계획 업무추진과정

기 본 계 획

- 개발 여건 분석
- 기 본 구 상
- 기본계획(부문별)
- 사 업 계 획
- 성 과 품 작 성

⇩

기 본 설 계

- 기본 계획 검토
- 기본설계(부문별)
- 설계 도서 작성

⇩

실 시 설 계

- 기본 설계 검토
- 실시설계(부문별)
- 설계 도서 작성

5-4 품 산정의 원단위 산정과 기준

5-4-1 표준품 산정내역

○ 표준품 산정의 기준이 되는 비목은 제1장 총칙에서 제시한 비목을 중심으로 하였으며, 이는 문화재·사적지계획에 필요한 사항만을 대상으로 한다.

○ 표준품 산정의 기본이 되는 직접인건비 품의 작업항목별 보할은 업무의 난이도를 감안하여 설정토록 한다.

1. 조사 및 측량, 토질조사 및 시험

○ 측량, 토질조사, 토지적성평가, 문화재지표조사 등의 품은 별도 적용한다.

2. 기본계획의 표준산정내역

종 별		내 용	세부항목	단 위	비 고
직접비	직접인건비	1.개발여건분석		인·일	
		2.기본구상		〃	
		3.기본계획(부문별)		〃	
		4.사업계획		〃	
		5.성과품 작성		〃	
		6.기술협의	①공청회 / 주민설명회 ②주민간담회 / 시민계획단 ③위원회 심의 지원 ④관계기관 협의	〃 〃 〃 〃	
	직접경비	여비, 인쇄비, 조감도, 회의준비비, 현장운영비 등		식	제1장 총칙참조
간접비	제경비	직접인건비×120%		〃	〃
	기술료	(직접인건비+제경비)×30%		〃	〃

주 : ①본 사업에 관련되는 부수적인 업무인 다음 업무의 비용은 제1장 총칙에 정한 바에 따라 별도로 지급하여야 한다.

-각종 측량, 조사, 토질조사 및 시험비용

-모형, 투시도 또는 조감도 제작비용

-5부를 초과하는 설계도 인쇄 및 청사진비

-위탁자의 요구에 의하거나 수탁자의 책임에 귀속하지 아니하는 사유로 인한 계획의 변동과 같은 엔지니어링사업대가

②각종영향평가는 별도의 엔지니어링활동업무로 산정한다.

3. 기본설계, 실시설계의 표준산정내역

○ 기본설계와 실시설계의 품 산정은 엔지니어링사업대가의 기준 중 건설부문 공사비요율을 적용한다.

5-4-2 산정 기준

1. 계획·기준면적의 설정

○ 기준면적의 설정을 위해 이미 지정된 문화재 및 사적지, 민속촌의 면적분포 현황을 분석하여 빈도가 가장 높은 10만㎡를 기준면적으로 산정 하였다.

○ 계획면적은 고시된 경우는 법정계획면적을, 신설된 경우는 기본구상을 전제로 한 조사면적을 기준으로 한다.

2. 표준품의 산정방법

○ 표준품의 적용에 있어 기준면적과 계획면적의 차이, 계획대상지 지형의 복잡성 등에 따른 품 산정은 아래의 수정식에 따라 기준면적의 소요작업량을 수정하여 산정한다.

○ 소요작업량 = 기준면적소요작업량 × 면적보정계수(α) × 지형보정계수(β)

3. 계획안의 수정과 과업중지에 따른 산정방법

○ 계획안이 작성되고 주민공람, 의회보고 등 행정절차과정을 거쳐 계획안이 확정된 후 발주자의 사정에 의하여 계획안이 일부변경·재작업이 수행되는 경우에는 그 변경·재작업의 정도에 따라 엔지니어링사업대가의 50～100% 수준에서 비용을 추가 지급하여야 한다.

○ 과업수행 중 발주자의 사정에 따른 과업 중단으로 인해 정부 회계연도가 경과되어 현저한 비용의 차이가 발생하였을 경우에는 엔지니어링사업대가를 당해 신년도의 노임단가를 기준으로 재산정하여야 한다.

5-4-3 단위별 변화수정과 보정

1. 작업량 보정계수 산정

1) 면적의 대소에 대한 작업량 보정계수 산정

○ 계획면적이 기준면적을 초과하거나 못 미치는 경우의 직접인력 소요작업량의 산정을 위한 면적보정계수(α)는 다음의 식에 의해 산정한다.

$$\alpha = \left(\frac{\text{계획면적}}{\text{기준면적}}\right)^{0.62} = \left(\frac{A}{10}\right)^{0.62}$$

A : 계획면적(만㎡)
α : 보정계수

계획면적별 보정계수

면 적(만㎡)	보정계수(α)	면 적 (만㎡)	보정계수(α)
4	0.567	19	1.489
5	0.651	20	1.537
6	0.729	21	1.584
7	0.802	22	1.630
8	0.871	23	1.676
9	0.937	24	1.721
10	1.000	25	1.765
11	1.061	26	1.808
12	1.120	27	1.851
13	1.177	28	1.893
14	1.232	29	1.935
15	1.286	30	1.976
16	1.338	31	2.017
17	1.390	32	2.057
18	1.440	33	2.096

※문화재, 사적지의 계획면적이 4만㎡미만이면 보정계수는 4만㎡를 적용한다.

2) 지형과 입지에 따른 보정계수 산정

○ 계획대상지의 지형적 복잡성이 있는 경우 다음의 지형보정계수(β)를 적용하여 산정한다.

구 분	입지에 따른 보정계수(β)
내륙형 평지	1.0
내륙형 구릉지	1.2 ~ 1.4
내륙형 산지	1.2 ~ 1.5
도시형 평지/구릉지	1.2 ~ 1.4
도시형 산지	1.3 ~ 1.5
해안·호소형 평지/구릉지/산지	1.3 ~ 1.5

2. 직접인건비 소요 작업량 산정

○ 계획면적의 대소에 따른 직접인력 소요작업량의 산정방법은 아래와 같이 기준면적의 직능별 직접인력 소요작업량에 계획단위 보정계수($\alpha\ \beta$)를 곱하여 산출한다.

구 분	기준면적 (만㎡)	총작업량(인·일)					
		기술사	특 급	고 급	중 급	초 급	보조원
문화재·사적지 계획	10	20.0αβ	32.0αβ	95.0αβ	134.0αβ	174.0αβ	233.0αβ

5-5 표준단위 업무분류와 원단위

기술업무의 직접인력 소요작업량(면적 10만㎡ 기준)

(단위 : 인 · 일/표준단위)

구 분	업무내용	표준단위	소요인력(인·일)						비고
			기술사	특급	고 급	중 급	초 급	보조원	
1.개발여건 분석		10만㎡	3.0	5.0	16.0	20.0	24.0	45.0	
2.기본구상		10만㎡	5.0	8.0	25.0	39.0	44.0	64.0	
3.기본계획(부문별)		10만㎡	7.0	11.0	32.0	43.0	70.0	90.0	
4.사업계획		10만㎡	4.0	7.0	19.0	25.0	25.0	25.0	
5.성과품 작성		10만㎡	1.0	1.0	3.0	7.0	11.0	9.0	
총 계			20.0	32.0	95.0	134.0	174.0	233.0	
6.기술협의	①공청회/주민설명회 ②주민간담회/시민계획단 ③위원회심의 지원 ④관계기관 협의	1식 1식 1식 1식	2.0 2.0 2.0 2.0	2.0 2.0 2.0 2.0	2.0 2.0 2.0 2.0	4.0 4.0 4.0 4.0	4.0 4.0 4.0 4.0	4.0 4.0 4.0 4.0	
	소 계		8.0	8.0	8.0	16.0	16.0	16.0	

주 : ①본 사업에 관련되는 부수적인 업무인 다음 업무의 비용은 제1장 총칙에 정한 바에 따라 별도로 지급하여야 한다.

-각종 측량, 조사, 토질조사 및 시험비용

-모형, 투시도 또는 조감도 제작비용

-5부를 초과하는 설계도 인쇄 및 청사진비

-위탁자의 요구에 의하거나 수탁자의 책임에 귀속하지 아니하는 사유로 인한 계획의 변동과 같은 엔지니어링사업대가

②각종영향평가는 별도의 엔지니어링활동업무로 산정한다.

③기술협의는 2회 이내 기준이며, 횟수가 늘어날 경우 증가배수에 해당하는 작업품과 비용을 가산한다. (필요항목 선택적 적용)

5-5-2 조사측량

○ 측량품을 별도 적용한다.

5-5-3 토질조사 및 시험

○ 토질조사 및 시험품을 별도 적용한다.

5-5-4 기본설계 및 실시설계

○ 기본설계 및 실시설계의 산출기준은 엔지니어링사업대가의 기준 중 건설부문 공사비 요율을 적용한다.

5-6 주요업무내용

구 분	업무내용	내 용
1.개발여건분석	①자연환경조사	·지형지세 및 경사도 분석 ·토질 및 토양, 기상자료 ·식생 및 경관특성
	②인문환경조사	·관련법규 및 계획검토 ·관광환경자원조사
	③종합분석	·제반현황의 종합적 분석 ·개발잠재력 및 문제점 검토
2.기본구상	①개발방향설정	·개발잠재력에 의한 개발방향설정
	②계획지표설정	·이용인구의 구성, 규모설정
	③토지이용체계구상	·공간구성체계설정 ·토지이용구상안 작성
	④동선체계구상	·이용자의 이용체계구상 ·토지이용에 따른 기능별 동선구상
	⑤유치시설종류 및 규모설정	·적정수용능력판단 ·시설 종류 및 규모설정
3.기본계획 (부문별)	①토지이용계획	·계획내용을 반영한 토지의 용도배분 ·토지이용종합계획수립
	②교통동선계획	·부지 내·외부의 연계, 주차 및 교차로의 효율적 처리 ·부지 내 도로계획
	③시설배치계획	·주요시설물(건축·조경)의 배치계획
	④식재계획	·식재계획
	⑤공급처리시설계획	·상하수도, 전기통신 부문에 대한 용량추정 및 공급처리방안
4.사업계획	①개발추진계획	·개략공사비 산정 ·공종별, 재원별 투자계획 ·단계별, 연차별 투자계획
	②관리운영계획	·환경보전방안제시 ·관리체계 및 대책제시 ·운영방안제시

5-7 표준성과품

성과구분	표준성과도서			비 고
	구 분	규 격	제출부수	
현황도	·위치도 ·현황종합분석도	1/50,000～1/25,000 1/50,000～1/5,000	1부 〃	
계획도	·종합기본계획도 ·토지이용계획도 ·교통동선계획도 ·시설물배치계획도 ·식재계획도 ·공급처리시설계획도	1/5,000～1/3,000 〃 〃 〃 〃 〃	〃 〃 〃 〃 〃 〃	조경, 건축
보고서	·보고서 ·계획관련도서	발주자와 협의결정	발주자와 협의결정	

주 : ①제출부수 및 성과품 종류가 증가할 경우에는 증가배수에 해당하는 작업품과 비용을 가산한다.
②계획보고서 및 기타 관련 자료의 규격 및 제출부수는 발주자와의 협의에 의하여 비용을 산정한다.

제10장 조경특화계획

제1절 도로조경계획

제2절 시가지 광장과 건축관련 공간계획

제3절 단지조경계획

제4절 환경·생태복원계획

제5절 개발제한구역 조경설계검토 도서 작성

제1절 도로조경계획

1-1 정 의

○ 도로조경이란 고속도로 및 일반도로(국도, 지방도, 군도 등)변의 완충녹지 및 주변지역에 대해서 자연을 최대한 보존하고, 도로개설에 의해 훼손된 경관을 복구함으로써 운전자에게는 심리적 안정감을 주고 여행자에게는 쾌락감과 시각적 즐거움을 주며, 동시에 도로의 기능을 보강하기 위하여 시행되는 작업을 말한다.

1-2 자료제공의 전제

○ 도로조경계획에 필요한 모든 관련 자료는 원칙적으로 발주자가 제공하는 것으로 하되, 발주자가 보유하지 않는 자료는 엔지니어링사업자가 수집한다.

○ 발주자가 제공하지 못하는 자료의 조사에 있어서는 그 규모·내용에 의거하여 별도의 엔지니어링사업대가를 산정하여 엔지니어링사업자가 수행하며, 관련 자료의 기밀성과 광범위한 자료가 필요한 경우 조사·분석에 요구되는 상당기간과 자료수집비용이 전제되어야 한다.

1-3 업무범위와 추진과정

1-3-1 업무범위

○ 도로조경계획의 업무범위는 도로경관의 형성을 위한 도로변의 식재계획, 조경시설계획 등이다.

1-3-2 추진과정

○ 타 부처(관계기관)와 협의나 전문가 자문 등에 소요되는 기간은 과업수행기간에서 제외하여 그 소요기간 만큼 과업수행기간을 연장하여야 한다.

도로조경계획 업무추진과정

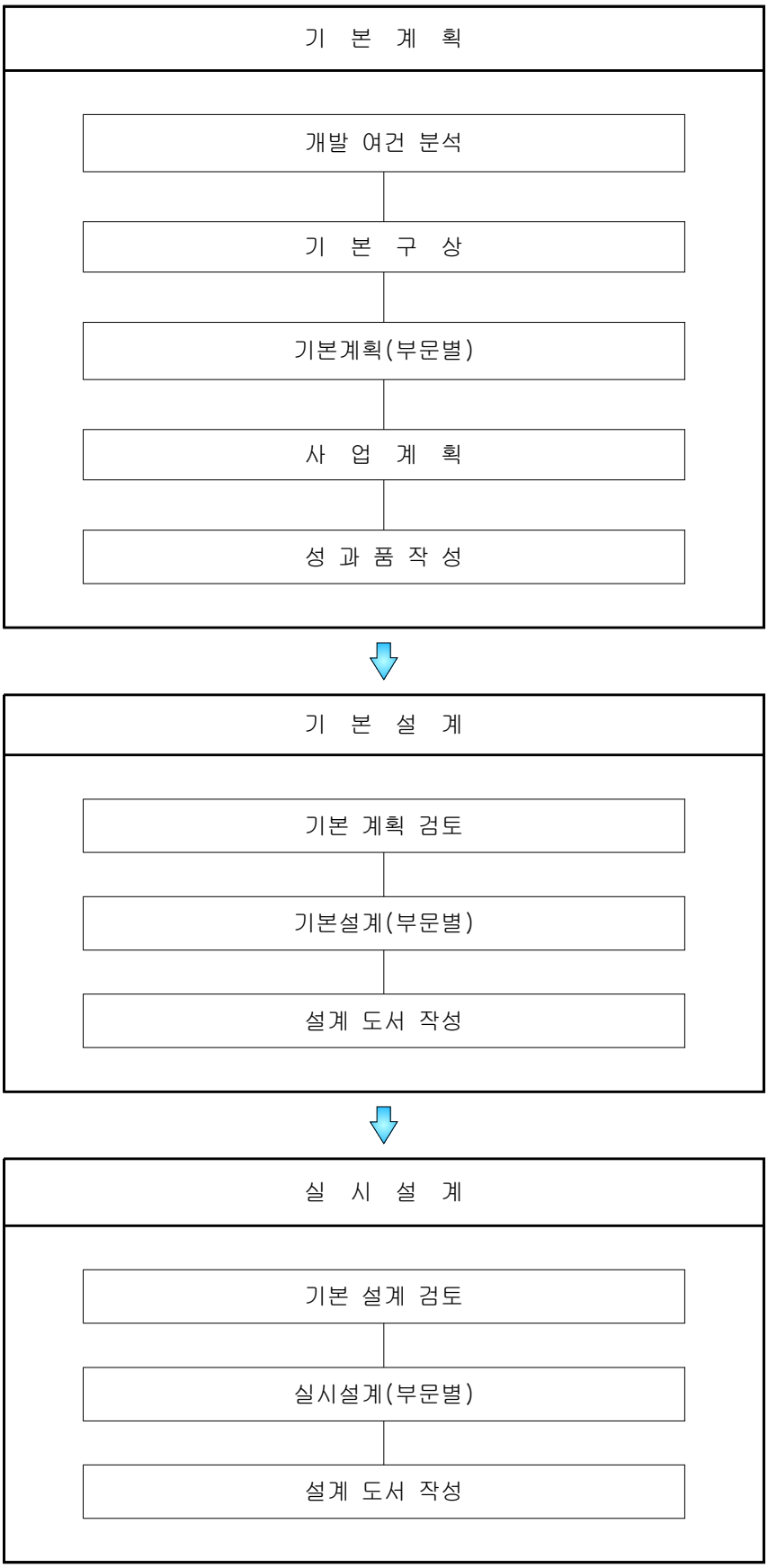

1-4 품 산정의 원단위 산정과 기준

1-4-1 표준품 산정내역

○ 표준품 산정의 기준이 되는 비목은 제1장 총칙에서 제시한 비목을 중심으로 하였으며, 도로조경계획에 필요한 사항만을 대상으로 한다.

○ 표준품 산정의 기본이 되는 직접인건비 품의 작업항목별 보할은 기존의 경험적 내용 및 업무의 난이도를 감안하여 설정토록 한다.

1. 조사 및 측량, 토질조사

○ 측량, 토질조사, 토지적성평가, 문화재지표조사 등의 품은 별도 적용한다.

2. 기본계획

종 별		내 용	세부항목	단 위	비 고
직접비	직접인건비	1.개발여건분석		인·일	
		2.기본구상		〃	
		3.기본계획		〃	
		4.사업계획		〃	
		5.성과품 작성		〃	
		6.기술협의	①공청회 / 주민설명회 ②주민간담회 / 시민계획단 ③위원회심의 지원 ④관계기관 협의	〃 〃 〃 〃	
	직접경비	여비, 인쇄비, 조감도, 회의준비비, 현장운영비 등		식	제1장 총칙참조
간접비	제경비	직접인건비×120%		〃	〃
	기술료	(직접인건비+제경비)×30%		〃	〃

주 : ①도로조경계획에 관련되는 부수적인 업무인 다음 업무의 비용은 제1장 총칙에 정한 바에 따라 별도로 지급하여야 한다.

-각종 측량, 조사, 토질조사 및 시험비용

-모형, 투시도 또는 조감도 제작비용

-5부를 초과하는 설계도 인쇄 및 청사진비

-위탁자의 요구에 의하거나 수탁자의 책임에 귀속하지 아니하는 사유로 인한 계획의 변동과 같은 엔지니어링사업대가

②각종영향평가는 별도의 엔지니어링활동업무로 산정한다.

3. 기본설계, 실시설계의 표준산정내역

○ 기본설계와 실시설계의 품 산정은 엔지니어링사업대가의 기준 중 건설부문 공사비요율을 적용한다.

1-4-2 산정 기준

1. 계획·기준연장의 설정

○ 기준 원단위 설정은 도로의 경우 연장 10km를 기준으로 하고, 인터체인지나, 주차장, 휴게소 등의 지역은 각1개소를 기준으로 산정한다.

○ 계획연장(시설 수)은 기본구상을 전제로 한 조사연장을 기준으로 한다.

2. 표준품의 산정방법

○ 도로조경계획의 직접인건비 산정방법은 표준지구의 원단위에 보정계수를 적용하여 품 산정한다.

○ 소요작업량 = 기준면적소요작업량 × 연장보정계수(α) × 지형보정계수(β) + 부대시설소요작업량

3. 계획안의 수정과 과업중지 등에 따른 산정방법

○ 계획안이 작성되고 주민공람, 의회보고 등 행정절차과정을 거쳐 계획안이 확정된 후 발주자의 사정에 의하여 계획안이 일부변경·재작업이 수행되는 경우에는 그 변경·재작업의 정도에 따라 엔지니어링사업대가의 50～100% 수준에서 비용을 추가 지급하여야 한다.

○ 과업수행 중 발주자의 사정에 따른 과업 중단으로 인해 정부 회계연도가 경과되어 현저한 비용의 차이가 발생하였을 경우에는 엔지니어링사업대가를 당해 신년도의 노임단가를 기준으로 재산정하여야 한다.

1-4-3 단위별 변화수정과 보정

1. 작업량 보정계수 산정

1) 도로연장의 변화에 대한 작업량 보정계수 산정

○ 계획도로연장이 기준연장(10km)을 초과하거나 못 미치는 경우의 직접인력 소요작업량의 산정을 위한 연장보정계수(α)는 다음의 식에 의해 산정한다.

$$\alpha = \left(\frac{\text{계획연장}}{\text{기준연장}}\right)^{0.62} = \left(\frac{A}{10}\right)^{0.62}$$

α = 연장보정계수
A = 계획연장(km)

계획연장에 대한 보정계수

연장(km)	보정계수(α)	연장(km)	보정계수(α)	연장(km)	보정계수(α)
4	0.567	14	1.232	24	1.721
5	0.651	15	1.286	25	1.765
6	0.729	16	1.338	26	1.808
7	0.802	17	1.390	27	1.851
8	0.871	18	1.440	28	1.893
9	0.937	19	1.489	29	1.935
10	1.000	20	1.539	30	1.976
11	1.061	21	1.584	31	2.017
12	1.120	22	1.630	32	2.057
13	1.177	23	1.676	33	2.096

주 : ①계획연장이 4km미만이면 보정계수는 4km 보정계수를 적용한다.
②도로의 조경면적이 현저히 넓은 경우에는 10~30%의 범위 내에서 작업량을 보정 할 수 있다.

2) 지형의 변화에 대한 작업량 보정계수 산정

○ 계획대상지의 지형적 복잡성에 따른 보정계수는 다음을 적용한다.

구 분	지형보정계수(β)
평 지	1.0
산 지	1.2

3) 부대시설 개소의 변화에 대한 작업량 보정계수 산정

○ 부대시설의 개소가 기준부대시설 개소(1개소)를 초과하거나 못 미치는 경우의 직접인력 소요작업량의 산정을 위한 부대시설 개소보정계수(γ)는 다음의 식에 의해 산정한다.

$$\gamma = \left(\frac{\text{계획시설수}}{\text{기준시설수}}\right)^{1.0} = \left(\frac{E}{1}\right)^{1.0}$$

γ = 개소보정계수
E = 계획시설수(개소)

2. 직접인건비 소요 작업량 산정

○ 계획연장(개소)의 대소에 따른 직접인력소요작업량의 산정방법은 아래와 같이 기준면적의 직능별 직접인력 소요작업량에 계획단위 보정계수(α, β, γ)를 곱하여 산출한다

구 분	기 준	총작업량(인·일)					
		기술사	특 급	고 급	중 급	초 급	보조원
도로지역	10㎞	5.0αβ	8.0αβ	21.0αβ	31.0αβ	43.0αβ	60.0αβ
부대시설	1개소	2.0αγ	2.5αγ	6.0αγ	6.0αγ	7.0αγ	8.0αγ

1-5 표준단위 업무분류와 원단위

기술업무의 직접인력 소요작업량(도로지역 : 연장 10㎞ 기준)

(단위 : 인 · 일/표준단위)

구 분	업무내용	표준단위	소요인력						비고
			기술사	특 급	고 급	중 급	초 급	보조원	
1.개발여건분석		10Km	0.8	1.2	3.0	4.0	6.0	10.0	
2.기본구상		10Km	1.2	1.8	5.0	8.0	10.0	15.0	
3.기본계획		10Km	1.6	2.4	6.0	10.0	15.0	20.0	
4.사업계획		10Km	0.7	1.3	4.0	5.0	6.0	7.0	
5.성과품작성		10Km	0.7	1.3	3.0	4.0	6.0	8.0	
총 계			5.0	8.0	21.0	31.0	43.0	60.0	
6.기술협의	①공청회/주민설명회	1식	2.0	2.0	2.0	4.0	4.0	4.0	
	②주민간담회/시민계획단	1식	2.0	2.0	2.0	4.0	4.0	4.0	
	③위원회심의 지원	1식	2.0	2.0	2.0	4.0	4.0	4.0	
	④관계기관 협의	1식	2.0	2.0	2.0	4.0	4.0	4.0	
	소 계		8.0	8.0	8.0	16.0	16.0	16.0	

주 : ①도로지역의 조경면적이 현저히 넓은 경우에는 10~30%의 범위내에서 작업량을 보정할 수 있다

②기술협의는 2회 이내 기준이며, 횟수가 늘어날 경우 증가배수에 해당하는 작업품과 비용을 가산한다. (필요항목 선택적 적용)

기술업무의 직접인력 소요작업량(부대시설 : 1개소 기준)

(단위 : 인 · 일/표준단위)

구 분	업무내용	표준단위	소요인력(인·일)						비고
			기술사	특 급	고 급	중 급	초 급	보조원	
1.개발여건분석		1개소	0.2	0.3	0.5	1.0	1.5	2.0	
2.기본구상		1개소	0.4	0.6	1.0	1.5	1.5	1.0	
3.기본계획		1개소	1.0	1.0	2.0	1.5	1.5	2.0	
4.사업계획		1개소	0.2	0.3	1.5	1.0	1.0	1.0	
5.성과품작성		1개소	0.2	0.3	1.0	1.0	1.5	2.0	
총 계			2.0	2.5	6.0	6.0	7.0	8.0	
6.기술협의	①공청회/주민설명회	1식	2.0	2.0	2.0	4.0	4.0	4.0	
	②주민간담회/시민계획단	1식	2.0	2.0	2.0	4.0	4.0	4.0	
	③위원회심의 지원	1식	2.0	2.0	2.0	4.0	4.0	4.0	
	④관계기관 협의	1식	2.0	2.0	2.0	4.0	4.0	4.0	
	소 계		8.0	8.0	8.0	16.0	16.0	16.0	

주 : ①기술협의는 2회 이내 기준이며, 횟수가 늘어날 경우 증가배수에 해당하는 작업품과 비용을 가산한다. (필요항목 선택적 적용)

1-5-2 조사측량

○ 측량품을 별도 적용한다.

1-5-3 토질조사 및 시험

○ 토질조사 및 시험품을 별도 적용한다.

1-5-4 기본 및 실시설계

○ 기본설계 및 실시설계의 산출기준은 엔지니어링사업대가의 기준 중 건설부문 공사비 요율을 적용한다.

1-6 주요업무내용

구 분	업무내용	내 용
1.개발여건분석	①자연환경조사	·지형지세 및 경사도 분석 ·토질 및 토양, 기상자료 ·식생 및 경관특성
	②인문환경조사	·관련법규 및 계획검토 ·관광환경자원조사
	③종합분석	·제반현황의 종합적 분석 ·개발잠재력 및 문제점 검토
2.기본구상	①개발방향설정	·개발잠재력에 의한 개발방향설정
	②계획지표설정	·계획개념 및 계획기준설정
	③기본구상	·공간구성체계설정 및 시설지별 구상안 작성 ·시설 종류 및 규모설정
3.기본계획	①시설배치계획	·주요시설물(건축·조경)의 배치계획
	②식재계획	·식재계획
4.사업계획	①개발추진계획	·개략공사비 산정 ·공종별, 재원별 투자계획 ·단계별, 연차별 투자계획
	②관리운영계획	·환경보전방안제시 ·관리체계 및 대책제시 ·운영방안제시

1-7 표준성과품 (기본계획)

성과구분	표준성과도서			비 고
	구 분	규 격	제출부수	
현황도	·위치도 ·현황종합분석도	1/50,000～1/25,000 1/50,000～1/5,000	1부 〃	
계획도	·종합기본계획도 ·토지이용계획도 ·교통동선계획도 ·시설물배치계획도 ·식재계획도 ·공급처리시설계획도	1/5,000～1/3,000 〃 〃 〃 〃 〃	〃 〃 〃 〃 〃 〃	조경, 건축
보고서	·계획보고서 ·계획관련도서	발주자와 협의결정	발주자와 협의결정	

주 : ①제출부수 및 성과품 종류가 증가할 경우에는 증가배수에 해당하는 작업품과 비용을 가산한다.
②계획보고서, 기타 관련 자료의 규격 및 제출부수는 발주자와의 협의에 의하여 비용을 산출하여 산정한다.

제2절 시가지 광장과 건축관련 공간계획

2-1 정 의

○ 시가지 광장과 건축 관련공간에 대한 계획이란 시가지내에 위치하는 각종 광장이나 공공건물(공용의 청사 등), 사무실 건물, 호텔, 상가 및 주택 등 단위건물의 주변이나 이와 부대하여 시행하는 실내외의 사업에 관한 계획을 말한다.

2-2 자료제공의 전제

○ 시가지 광장과 건축 관련공간계획에 필요한 모든 관련 자료는 원칙적으로 발주자가 제공하는 것으로 하되, 발주자가 보유하지 않는 자료는 엔지니어링사업자가 수집한다.

○ 발주자가 제공하지 못하는 자료의 조사에 있어서는 그 규모·내용에 의거하여 별도의 엔지니어링사업대가를 산정하여 엔지니어링사업자가 수행하며, 당해 관련 자료의 기밀성과 광범위한 자료가 요구되는 경우 조사·분석에 필요한 상당기간과 자료수집비용이 전제되어야 한다.

2-3 업무범위 및 추진과정

2-3-1 업무범위

○ 시가지 광장과 건축 관련공간계획의 업무범위는 기본계획, 기본설계 및 실시설계 등을 주요범위로 한다.

2-3-2 추진과정

○ 타 부처(관계기간)와의 협의나 전문가 자문 등에 소요되는 기간은 과업수행기간에서 제외하여 그 소요기간 만큼 과업수행기간을 연장하여야 한다.

시가지 광장과 건축 관련공간계획 업무추진과정

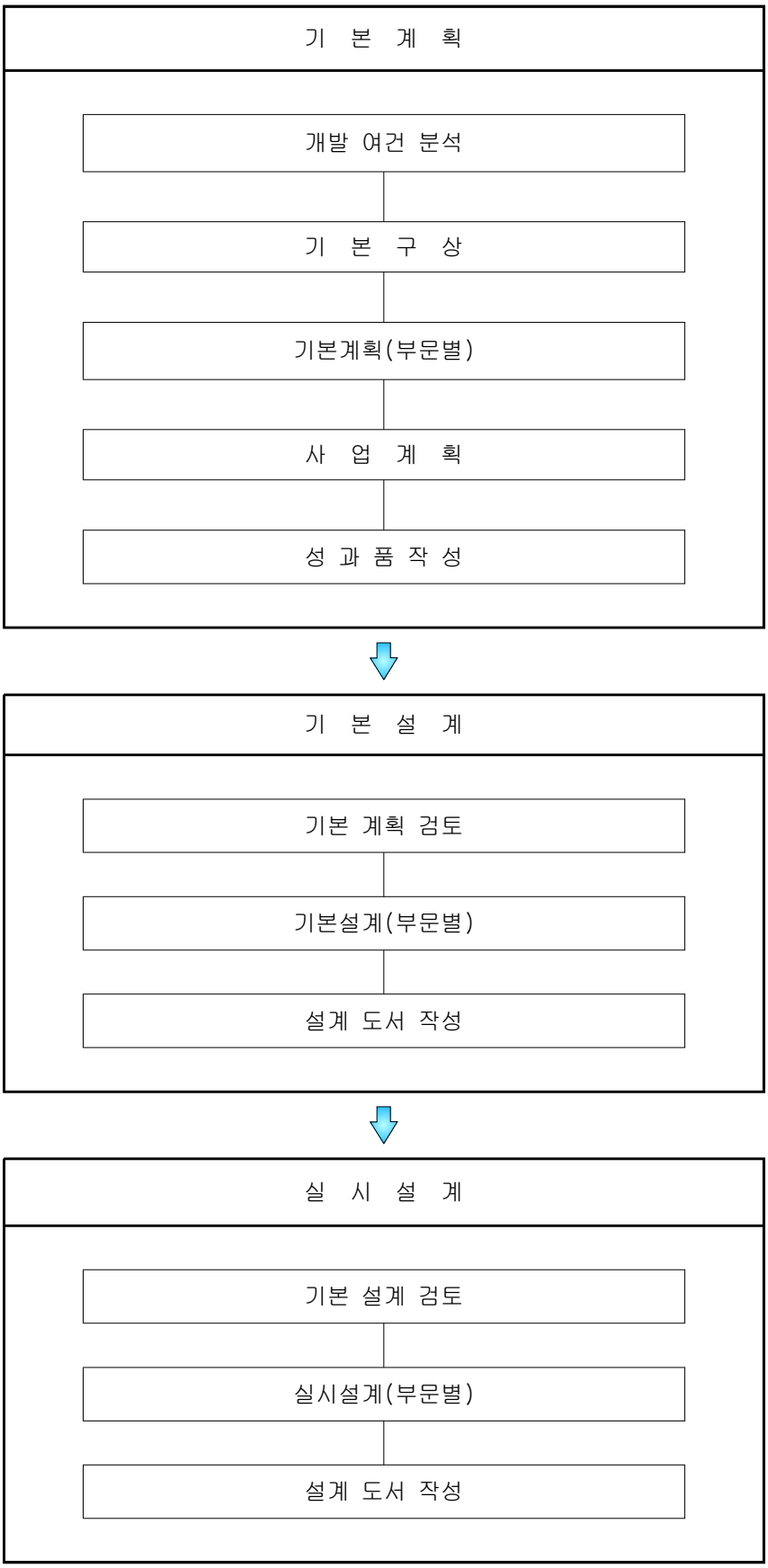

2-4 품 산정의 원단위 산정과 기준

2-4-1 표준품 산정내역

○ 표준품 산정의 기준이 되는 비목은 제1장 총칙에서 제시한 비목을 중심으로 하였으며, 시가지 광장과 건축 관련공간계획에 필요한 사항만을 대상으로 한다.

○ 표준품 산정의 기본이 되는 직접인건비 품의 작업항목별 보할은 기존의 경험적 내용 및 업무의 난이도를 감안하여 설정토록 한다.

1. 조사 및 측량, 토질조사

○ 측량, 토질조사, 토지적성평가, 문화재지표조사 등의 품은 별도 적용한다.

2. 기본계획

종 별		내 용	세부항목	단 위	비 고
직접비	직접인건비	1.개발여건분석		인·일	
		2.기본구상		〃	
		3.기본계획(부문별)		〃	
		4.사업계획		〃	
		5.성과품 작성		〃	
		6.기술협의	①공청회 / 주민설명회 ②주민간담회 / 시민계획단 ③위원회 심의 지원 ④관계기관 협의	〃 〃 〃 〃	
	직접경비	여비, 인쇄비, 조감도, 회의준비비, 현장운영비 등		식	제1장 총칙참조
간접비	제경비	직접인건비×120%		〃	〃
	기술료	(직접인건비+제경비)×30%		〃	〃

주 : ①시가지 광장과 건축 관련공간계획에 관련되는 부수적인 업무인 다음 업무의 비용은 제1장 총칙에 정한 바에 따라 별도로 지급하여야 한다.

-각종 측량, 조사, 토질조사 및 시험비용

-모형, 투시도 또는 조감도 제작비용

-5부를 초과하는 설계도 인쇄 및 청사진비

-위탁자의 요구에 의하거나 수탁자의 책임에 귀속하지 아니하는 사유로 인한 계획의 변동과 같은 엔지니어링사업대가

②각종영향평가는 별도의 엔지니어링활동업무로 산정한다.

3. 기본설계, 실시설계의 표준산정내역

○ 기본설계와 실시설계의 품 산정은 엔지니어링사업대가의 기준 중 건설부문 공사비요율을 적용한다.

2-4-2 산정 기준

1. 계획·기준면적의 설정

○ 기준면적 원단위 설정은 1만㎡를 기준으로 한다.

○ 계획면적은 기본구상면적 또는 과업면적을 원칙으로 한다.

2. 표준품의 산정방법

○ 시가지 광장과 건축관련 공간계획의 직접인건비 산정방법은 기준면적의 원단위에 계획면적에 의한 보정계수를 적용하여 품 산정 한다.

소요작업량 = 기준면적소요작업량 × 면적보정계수(α)

3. 계획안의 수정과 과업중지에 따른 산정방법

○ 계획안이 작성되고 주민공람, 의회보고 등 행정절차과정을 거쳐 계획안이 확정된 후 발주자의 사정에 의하여 계획안이 일부변경·재작업이 수행되는 경우에는 그 변경·재작업의 정도에 따라 엔지니어링사업대가의 50～100% 수준에서 비용을 추가 지급하여야 한다.

○ 과업수행 중 발주자의 사정에 따른 과업 중단으로 인해 정부 회계년도가 경과되어 현저한 비용의 차이가 발생하였을 경우에는 엔지니어링사업대가를 당해 신년도의 노임단가를 기준으로 재산정하여야 한다.

2-4-3 단위별 변화수정과 보정

1. 면적의 변화에 대한 작업량 보정계수 산정

○ 시가지 광장과 건축관련 공간계획면적이 기준면적을 초과하거나 이에 못 미치는 경우의 직접인력 소요작업량의 산정을 위한 각 작업내용별 보정계수(α)는 다음과 같이 산정한다.

$$\alpha = \left(\frac{\text{계획면적}}{\text{기준면적}}\right)^{0.62} = \left(\frac{A}{1}\right)^{0.62}$$

α = 보정계수
A = 계획면적(만㎡)

계획면적에 대한 작업량 보정계수

계획면적(만㎡)	보정계수(α)	계획면적(만㎡)	보정계수(α)
0.4	0.567	1.9	1.489
0.5	0.651	2.0	1.537
0.6	0.729	2.1	1.584
0.7	0.802	2.2	1.630
0.8	0.871	2.3	1.676
0.9	0.937	2.4	1.721
1.0	1.000	2.5	1.765
1.1	1.061	2.6	1.808
1.2	1.120	2.7	1.851
1.3	1.177	2.8	1.893
1.4	1.232	2.9	1.935
1.5	1.286	3.0	1.976
1.6	1.338	3.1	2.017
1.7	1.390	3.2	2.057
1.8	1.440	3.3	2.096

※계획면적이 4,000㎡ 미만이면 보정계수는 4,000㎡의 보정계수를 적용한다.

2. 직접인건비 소요 작업량 산정

○ 계획면적의 대소에 따른 직접인력 소요작업량의 산정방법은 아래와 같이 기준면적의 직능별 직접인력 소요작업량에 계획단위 보정계수(α)를 곱하여 산출한다.

구 분	기준면적 (만㎡)	총작업량(인·일)					
		기술사	특 급	고 급	중 급	초 급	보조원
시가지광장과 건축관련 공간계획	1.0	1.5α	2.5α	5.0α	7.5α	9.0α	11.0α

2-5 표준단위 업무분류와 원단위

2-5-1 조사측량

○ 측량품을 별도 적용한다.

2-5-2 기본계획

기술업무의 직능별 직접인력 소요 작업량(면적 1만㎡ 기준)

(단위 : 인·일/표준단위)

업무내용		표준단위	소요인력						비고
			기술사	특급	고 급	중 급	초 급	보조원	
1.개발여건분석		1만㎡	0.2	0.3	0.5	1.0	1.0	2.0	
2.기본구상		1만㎡	0.4	0.6	1.5	2.0	2.0	2.0	
3.기본계획		1만㎡	0.5	1.0	2.0	2.5	3.0	5.0	
4.사업계획		1만㎡	0.3	0.3	0.5	1.0	1.0	1.0	
5.성과품작성		1만㎡	0.2	0.3	0.5	1.0	2.0	1.0	
총 계			1.5	2.5	5.0	7.5	9.0	11.0	
6.기술협의	①공청회/주민설명회	1식	2.0	2.0	2.0	4.0	4.0	4.0	
	②주민간담회/시민계획단	1식	2.0	2.0	2.0	4.0	4.0	4.0	
	③위원회심의 지원	1식	2.0	2.0	2.0	4.0	4.0	4.0	
	④관계기관 협의	1식	2.0	2.0	2.0	4.0	4.0	4.0	
	소 계		8.0	8.0	8.0	16.0	16.0	16.0	

주 : ①각종영향성검토 및 각종영향평가업무는 별도의 엔지니어링활동업무로 계상한다.

②기술협의는 2회 이내 기준이며, 횟수가 늘어날 경우 증가배수에 해당하는 작업품과 비용을 가산한다. (필요항목 선택적 적용)

2-5-3 토질조사 및 시험

○ 토질조사 및 시험품을 별도 적용한다.

2-5-4 기본설계 및 실시설계

○ 기본설계 및 실시설계의 산출기준은 엔지니어링사업대가의 기준 중 건설부문 공사비 요율을 적용한다.

2-6 주요업무내용

구 분	업무내용	내 용
1.개발여건분석	①자연환경조사	·지형지세 및 경사도 분석 ·토질 및 토양, 기상자료 ·식생 및 경관특성
	②인문환경조사	·배후지의 인구변화, 소득수준변화 ·관련법규 및 계획검토 ·관광환경자원조사
	③종합분석	·제반현황의 종합적 분석 ·개발잠재력 및 문제점 검토
2.기본구상	①개발방향설정	·개발잠재력에 의한 개발방향설정
	②계획지표설정	·이용인구의 구성, 규모설정
	③토지이용체계구상	·공간구성체계설정 ·토지이용구상안 작성
	④동선체계구상	·이용자의 이용체계구상 ·토지이용에 따른 기능별 동선구상
	⑤유치시설종류 및 규모설정	·시설 종류 및 규모설정
3.기본계획 (부문별)	①토지이용계획	·계획내용을 반영한 토지의 용도배분 ·토지이용종합계획 수립
	②교통동선계획	·부지 내외·부의 연계, 주차 및 교차로의 효율적 처리 ·부지내 도로계획
	③시설배치계획	·주요시설물(건축·조경)의 배치계획
	④식재계획	·식재계획
	⑤공급처리시설계획	·상·하수도, 전기통신 부문에 대한 용량추정 및 공급처리방안
4.사업계획	①개발추진계획	·개략공사비 산정 ·공종별, 재원별, 단계별, 연차별 투자계획
	②관리운영계획	·환경보전방안제시 ·관리체계 및 대책제시 ·운영방안제시

2-7 표준성과품

성과구분	표준성과도서			비 고
	구 분	규 격	제출부수	
현황도	·위치도 ·현황종합분석도	1/50,000~1/25,000 1/50,000~1/5,000	1부 〃	
계획도	·종합기본계획도 ·토지이용계획도 ·교통동선계획도 ·시설물배치계획도 ·식재계획도 ·공급처리시설계획도	1/5,000~1/3,000 〃 〃 〃 〃 〃	〃 〃 〃 〃 〃 〃	조경, 건축
보고서	·계획보고서 ·계획관련도서	발주자와 협의결정	발주자와 협의결정	

주 : ①제출부수 및 성과품 종류가 증가할 경우에는 증가배수에 해당하는 작업품과 비용을 가산한다.
②계획보고서, 기타 관련 자료의 규격 및 제출부수는 발주자와의 협의에 의하여 비용을 산출하여 산정한다.

제3절 단지조경계획

3-1 정 의

○ 단지조경계획은 도시 및 주거환경정비법에 의한 도시재생사업, 도시개발법에 의한 도시개발사업, 산업입지및개발에관한법률에 의한 국가산업단지·일반산업단지·농공단지·첨단산업단지·준산업단지 등을 포함하며, 포괄적인 계획에 따라 지정·개발되는 일단의 토지에 대한 지목 또는 토지의 형질변경이나 공공시설의 설치변경 등 주거환경 또는 산업입지에 관련된 토지개발사업에 대하여 공원·녹지 전반에 관한 계획을 말한다.

3-2 자료제공의 전제

○ 단지조경계획에 필요한 모든 관련 자료는 원칙적으로 발주자가 제공하는 것으로 하되, 발주자가 보유하지 않는 자료는 엔지니어링사업자가 수집한다.

○ 발주자가 제공하지 못하는 자료의 조사에 있어서는 그 규모·내용에 의거하여 별도의 엔지니어링사업대가를 산정하여 엔지니어링사업자가 수행하며, 당해 관련 자료의 기밀성과 광범위한 자료가 요구되는 경우 조사·분석에 필요한 상당기간과 자료수집비용이 전제되어야 한다.

3-3 업무범위 및 추진과정

3-3-1 업무범위

1. 주택단지조경계획

○ 주택단지조경계획은 기본계획, 기본설계, 실시설계 등을 주요업무범위로 한다.

2. 산업단지조경계획

○ 산업단지조경계획은 기본계획, 기본설계, 실시설계를 주요업무범위로 한다.

3-3-2 추진과정

○ 타 부처(관계기관)와 협의나 전문가 자문 등에 소요되는 기간은 과업수행기간에서 제외하여 그 소요기간만큼 과업수행기간을 연장하여야 한다.

단지조경계획 업무추진과정

3-4 품 산정의 원단위 산정과 기준

3-4-1 표준품 산정내역

○ 표준품 산정의 기준이 되는 비목은 제1장 총칙에서 제시한 비목을 중심으로 하였으며, 단지개발계획 등의 계획수립에 필요한 사항만을 대상으로 한다.

○ 표준품 산정의 기본이 되는 직접인건비 품의 작업항목별 보할은 기존의 경험적 내용 및 업무의 난이도를 감안하여 설정토록 한다.

1. 조사 및 측량, 토질조사 및 시험

○ 측량, 토질조사, 토지적성평가, 문화재지표조사 등의 품은 별도 적용한다.

2. 기본계획

종 별		내 용	세부항목	단 위	비 고
직접비	직접인건비	1.개발여건분석	①자연환경 ②인문환경 ③종합분석	인·일 〃 〃	
		2.기본구상	①개발방향설정 ②계획개념설정 ③토지이용체계구상 ④동선체계구상 ⑤유치시설종류 및 규모설정	〃 〃 〃 〃 〃	
		3.기본계획 (시설지별)	①토지이용계획 ②교통동선계획 ③시설물배치계획 ④식재계획 ⑤공급처리시설계획	〃 〃 〃 〃 〃	
		4.사업계획	①사업투자계획 ②관리운영계획	〃 〃	
		5.성과품 작성	①보고서작성 및 편집 ②관련도서작성	〃 〃	
		6.기술협의	①공청회 / 주민설명회 ②주민간담회 / 시민계획단 ③위원회심의 지원 ④관계기관 협의	〃 〃 〃 〃	
	직접경비	여비, 인쇄비, 조감도, 회의준비비, 현장운영비 등		식	제1장 총칙참조
간접비	제경비	(직접인건비)×120%		〃	〃
	기술료	(직접인건비+제경비)×30%		〃	〃

주 : 단지개발계획과 관련되는 부수적인 업무인 조사, 측량, 토질조사 및 시험, 환경영향평가, 교통영향평가, 재해영향평가, 경제적 타당성분석, 도시·군관리계획에 의한 추가계획 등은 별도의 엔지니어링활동업무로 간주한다.

3. 기본설계, 실시설계의 표준산정내역

○ 기본설계와 실시설계의 품 산정은 엔지니어링사업대가의 기준 중 건설부문 공사비요율을 적용한다.

3-4-2 산정기준

1. 계획·기준면적의 설정

○ 기준면적은 주택단지개발계획 및 산업단지개발계획의 기준면적인 50만㎡로 하였으며, 직능별 직접인력 소요원단위는 기 작성된 공원계획 등의 투입기술자 비율을 감안하여 설정하였다.

·주택단지, 도시재개발, 환지방식, 캠퍼스, 주거환경개선사업	50만㎡
·산업단지, 유통(물류)단지	50만㎡

○ 계획면적은 고시된 경우 법정계획면적을, 신설된 경우는 기본구상을 전제로 한 조사면적을 기준으로 하되, 다음의 경우에는 계획면적에 포함시킨다.

- 강, 바다 등을 포함하는 지역은 강, 바다 등이 시설지구로 이용될 때 기준면적에 포함함을 원칙으로 한다.

○ 산업, 연구 및 주거기능이 포함된 복합산업단지의 경우 개발계획상 산업, 연구단지는 산업단지조경품을, 주택단지는 주택단지조경 품을 적용한다.

2. 표준품의 산정방법

○ 표준품의 적용에 있어 기준면적과 계획면적의 차이에 따른 품 산정은 아래의 수정식에 따라 기준면적의 소요작업량을 수정하여 산정한다.

소요작업량 = 기준면적소요작업량× 면적보정계수(α)

3. 계획안의 수정과 과업중지에 따른 산정방법

○ 계획안이 작성되고 주민공람, 의회보고 등 행정절차과정을 거쳐 계획안이 확정된 후 발주자의 사정에 의하여 계획안이 일부변경·재작업이 수행되는 경우에는 그 변경·재작업의 정도에 따라 엔지니어링사업대가의 50～100% 수준에서 비용을 추가 지급하여야 한다.

○ 과업수행 중 발주자의 사정에 따른 과업 중단으로 인해 정부 회계연도가 경과되어 현저한 비용의 차이가 발생하였을 경우에는 엔지니어링사업대가를 당해 신년도의 노임단가를 기준으로 재산정하여야 한다.

3-4-3 단위별 변화수정과 보정

1. 작업량 보정계수 산정

○ 표준품의 적용에 있어 계획면적이 기준면적을 초과하거나 못 미치는 경우의 직접인력 소요작업량의 산정을 위한 면적보정계수(α)는 다음의 식에 의해 산정한다.

·주택단지조경, 산업단지조경

$$\alpha = \left(\frac{\text{계획면적}}{\text{기준면적}}\right)^{0.6} = \left(\frac{A}{50}\right)^{0.6}$$

α : 보정계수
A : 계획면적(만㎡)

계획단위 면적별 보정계수

면적(A)		보정계수 (α)	면적(A)		보정계수 (α)
만㎡	만평		만㎡	만평	
3.3	1	0.196	70.0		1.224
5.0		0.251	75.0		1.275
10.0		0.381	80.0		1.326
15.0		0.486	90.0		1.423
16.5	5	0.514	100.0	≒30	1.516
20.0		0.577	132.0		1.790
25.0		0.660	150.0		1.933
30.0		0.736	165.0	50	2.047
33.0	10	0.779	200.0		2.297
40.0		0.875	231.0	70	2.505
50.0		1.000	264.0		2.714
60.0		1.116	300.0		2.930
66.0	20	1.181	330.0	100	3.103

주:계획면적이 3.3만㎡이하인 경우에는 3.3만㎡를 기준으로 하여 산정한다.

2. 직접인건비 소요 작업량 산정

○ 계획면적의 대소에 따른 직접인력 소요작업량의 산정방법은 아래와 같이 기준면적의 직능별 직접인력 소요작업량에 계획단위 보정계수(α)를 곱하여 산출한다.

구 분	기준면적 (만㎡)	총작업량(인·일)					
		기술사	특 급	고 급	중 급	초 급	보조원
주택단지등	50	16.0α	24.0α	81.0α	106.0α	115.0α	149.0α
산업단지등	50	10.0α	16.0α	50.0α	66.0α	70.0α	90.0α

3-5 표준단위 업무분류와 원단위

3-5-1 기본계획

기술업무의 직능별 직접인력 소요작업량(주택단지조경 등 : 50만㎡ 기준)

(단위 : 인·일/표준단위)

구 분	업무내용	표준단위	소요인력						비고
			기술사	특 급	고 급	중 급	초 급	보조원	
1.개발여건 분석	①자연환경	50만㎡	1.2	2.5	5.4	8.4	7.7	10.0	
	②인문환경	50만㎡	1.1	2.5	5.4	8.4	7.6	8.0	
	③종합분석	50만㎡	1.2	2.5	6.8	8.7	7.7	10.0	
	소 계		3.5	7.5	17.6	25.5	23.0	28.0	
2.기본구상	①개발방향설정	50만㎡	0.5	0.7	3.7	4.9	5.4	7.2	
	②계획개념설정	50만㎡	0.7	1.2	3.7	5.8	5.5	7.2	
	③토지이용체계구상	50만㎡	0.7	1.2	4.6	5.8	6.7	7.2	
	④동선체계구상	50만㎡	0.5	0.7	4.6	5.0	6.7	7.2	
	⑤유치시설종류 및 규모설정	50만㎡	0.6	0.7	3.7	5.0	6.7	7.2	
	소 계		3.0	4.5	20.3	26.5	31.0	36.0	
3.기본계획 (부문별)	①토지이용계획	50만㎡	0.8	1.3	6.2	7.8	6.4	11.2	
	②교통동선계획	50만㎡	0.8	1.3	4.4	6.0	6.4	11.2	
	③시설물배치계획	50만㎡	0.8	1.3	4.4	6.0	6.4	11.2	
	④식재계획	50만㎡	1.8	1.7	6.2	7.8	9.9	11.2	
	⑤공급처리시설계획	50만㎡	0.8	1.3	4.4	6.0	6.4	11.2	
	소 계		5.0	6.9	25.6	33.6	35.5	56.0	
4.사업계획	①사업투자계획	50만㎡	1.9	2.4	9.0	8.0	10.7	10.5	
	②관리운영계획	50만㎡	1.6	1.9	6.0	7.0	9.8	9.5	
	소 계		3.5	4.3	15.0	15.0	20.5	20.0	
5.성과품 작성	①보고서작성 및 편집	50만㎡	0.8	0.7	1.7	3.6	3.0	4.5	
	②관련도서작성	50만㎡	0.2	0.1	0.8	1.8	2.0	4.5	
	소 계		1.0	0.8	2.5	5.4	5.0	9.0	
총 계			16.0	24.0	81.0	106.0	115.0	149.0	
6.기술협의	①공청회/주민설명회	1식	2.0	2.0	2.0	4.0	4.0	4.0	
	②주민간담회/시민계획단	1식	2.0	2.0	2.0	4.0	4.0	4.0	
	③위원회심의 지원	1식	2.0	2.0	2.0	4.0	4.0	4.0	
	④관계기관 협의	1식	2.0	2.0	2.0	4.0	4.0	4.0	
	소 계		8.0	8.0	8.0	16.0	16.0	16.0	

주 : ①기술협의는 2회 이내 기준이며, 횟수가 늘어날 경우 증가배수에 해당하는 작업품과 비용을 가산한다. (필요항목 선택적 적용)

②각종영향성검토 및 각종영향평가업무는 별도의 엔지니어링활동업무로 계상한다.

기술업무의 직능별 직접인력 소요작업량(산업단지조경 등 : 50만㎡ 기준)

(단위 : 인 · 일/표준단위)

구 분	업무내용	표준단위	소요인력						비고
			기술사	특 급	고 급	중 급	초 급	보조원	
1.개발여건 분석	①자연환경	50만㎡	1.0	2.0	4.3	6.6	6.0	7.8	
	②인문환경	50만㎡	1.0	2.0	4.3	6.6	6.0	6.4	
	③종합분석	50만㎡	1.0	2.0	5.4	6.8	6.0	7.8	
	소 계		3.0	6.0	14.0	20.0	18.0	22.0	
2.기본구상	①개발방향설정	50만㎡	0.3	0.4	2.1	2.8	3.0	4.0	
	②계획개념설정	50만㎡	0.3	0.8	2.1	3.3	3.0	4.0	
	③토지이용체계구상	50만㎡	0.3	0.8	2.6	3.3	3.9	4.0	
	④동선체계구상	50만㎡	0.3	0.5	2.6	2.8	3.8	4.0	
	⑤유치시설종류 및 규모설정	50만㎡	0.3	0.5	2.1	2.8	3.8	4.0	
	소 계		1.5	3.0	11.5	15.0	17.5	20.0	
3.기본계획 (부문별)	①토지이용계획	50만㎡	0.5	0.7	3.5	4.4	3.6	6.3	
	②교통동선계획	50만㎡	0.5	0.7	2.5	3.4	3.6	6.3	
	③시설물배치계획	50만㎡	0.5	0.8	2.5	3.4	3.6	6.3	
	④식재계획	50만㎡	1.0	1.0	3.5	4.4	5.6	6.3	
	⑤공급처리시설계획	50만㎡	0.5	0.8	2.5	3.4	3.6	6.3	
	소 계		3.0	4.0	14.5	19.0	20.0	31.5	
4.사업계획	①사업투자계획	50만㎡	1.1	1.4	5.1	4.7	6.0	6.1	
	②관리운영계획	50만㎡	0.9	1.1	3.4	4.3	5.5	5.4	
	소 계		2.0	2.5	8.5	9.0	11.5	11.5	
5.성과품 작성	①보고서작성 및 편집	50만㎡	0.4	0.4	1.0	2.0	1.8	2.5	
	②관련도서작성	200	0.1	0.1	0.5	1.0	1.2	2.5	
	소 계		0.5	0.5	1.5	3.0	3.0	5.0	
총 계			10.0	16.0	50.0	66.0	70.0	90.0	
6.기술협의	①공청회/주민설명회	1식	2.0	2.0	2.0	4.0	4.0	4.0	
	②주민간담회/시민계획단	1식	2.0	2.0	2.0	4.0	4.0	4.0	
	③위원회심의 지원	1식	2.0	2.0	2.0	4.0	4.0	4.0	
	④관계기관 협의	1식	2.0	2.0	2.0	4.0	4.0	4.0	
	소 계		8.0	8.0	8.0	16.0	16.0	16.0	

주 : ①기술협의는 2회 이내 기준이며, 횟수가 늘어날 경우 증가배수에 해당하는 작업품과 비용을 가산한다. (필요항목 선택적 적용)

3-5-2 조사측량

○ 측량품을 별도 적용한다.

3-5-3 토질조사 및 시험

○ 토질조사 및 시험품을 별도 적용한다.

3-5-4 기본설계

○ 기본설계의 산출기준은 엔지니어링사업대가의 기준 중 건설부문 공사비요율을 적용한다.

3-5-5 실시설계

○ 실시설계의 산출기준은 엔지니어링사업대가의 기준 중 건설부문 공사비요율을 적용한다.

3-6 주요업무내용

구 분	업무내용	내 용
1.개발여건분석	①자연환경조사	·수계, 토양 및 지질, 지형, 지세 등의 조사 ·기온, 강수량, 풍향, 풍속, 천기일수 등의 조사 ·기타 식생 등 경관조사
	②인문환경조사	·배후지의 인구변화 ·관련법규 및 계획검토 ·토지이용현황, 교통시설, 기반시설 조사 ·역사성 등 지역성격 조사
	③종합분석	·제반현황의 종합적 분석 ·개발잠재력 및 문제점 검토
2.기본구상	①개발방향설정	·개발잠재력에 의한 개발방향설정
	②계획개념설정	·계획개념 도출 ·주제 및 특화전략수립
	③토지이용체계구상	·공간구성체계설정 ·토지이용구상안 작성
	④동선체계구상	·이용자의 공원 이용체계구상 ·토지이용에 따른 기능별 동선구상
	⑤유치시설종류 및 규모설정	·적정수용능력판단 ·시설종류 및 규모설정
3.기본계획 (시설지별)	①토지이용계획	·공간구성체계설정 ·토지이용종합계획수립
	②교통동선계획	·공간별 동선체계설정 ·동선계획
	③시설물배치계획	·주요시설물의 배치계획
	④식재계획	·식재계획
	⑤공급처리시설계획	·상하수도, 전기통신 등 공급처리 방안
4.사업계획	①사업투자계획	·개략공사비 산정 ·공종별, 재원별, 단계별, 연차별 투자계획
	②관리운영계획	·환경보전방안 제시 ·관리체계 및 대책 제시 ·운영방안 제시

3-7 표준성과품

성과구분	표준성과도서			비 고
	구 분	규 격	제출부수	
현황도	·위치도 ·현황종합분석도	1/50,000~1/25,000 1/50,000~1/5,000	1부 〃	
계획도	·종합기본계획도 ·토지이용계획도 ·동선계획도 ·시설물배치계획도 ·식재계획도 ·공급처리시설계획도	1/5,000~1/3,000 〃 〃 〃 〃 〃	〃 〃 〃 〃 〃 〃	
보고서	·계획보고서 ·계획관련도서	발주자와 협의결정	발주자와 협의결정	

주 : ①제출부수 및 성과품 종류가 증가할 경우에는 증가배수에 해당하는 작업품과 비용을 가산한다.
②계획보고서, 기타 관련 자료의 규격 및 제출부수는 발주자와의 협의에 의하여 비용을 산출하여 산정한다.

제4절 환경·생태복원계획

4-1 정 의

○ 환경생태복원계획은 자연형 하천복원, 산림식생복원, 담수생태계복원, 동물서식환경복원, 비탈(인공)면 녹화계획, 생태공원, 환경공원, 종합산림생태복원, 식물원, 훼손지(토취, 광산, 자연재해)복원 등으로 구분하며 우리의 정주환경 보호 및 이용을 증진하기 위하여 필요한 행위의 허용·제한과 환경·생태복원 시설 및 이용 프로그램 전반에 관한 계획 그리고 타당성 검토를 말한다.

4-2 자료제공의 전제

○ 환경·생태복원계획에 필요한 모든 관련자료(기본도면 등)는 원칙적으로 발주자가 제공하는 것으로 하되, 발주자가 보유하지 않는 자료는 엔지니어링사업자가 수집한다.

○ 발주자가 제공하지 못하는 자료의 조사에 있어서는 그 규모·내용에 의거하여 별도의 엔지니어링사업대가를 산정하여 엔지니어링사업자가 수행하며, 관련 자료의 기밀성과 광범위한 자료가 요구되는 경우 조사·분석에 필요한 상당기간과 자료수집비용이 전제되어야 한다.

4-3 업무범위와 추진과정

4-3-1 업무범위

○ 환경생태복원계획은 자연형 하천복원, 산림식생복원, 담수생태계복원, 동물서식환경복원, 비탈(인공)면 녹화계획, 사구복원, 습지복원, 생태공원, 환경공원, 종합산림생태복원, 식물원 등의 환경계획 및 복원계획으로서 타당성조사, 기본계획, 기본설계, 실시설계를 주요 업무범위로 한다.

4-3-2 추진과정

○ 타 부처(관계기관)와의 협의나 전문가 자문 등에 소요되는 기간은 과업수행기간에서 제외하여 그 소요기간만큼 과업수행기간을 연장하여야 한다.

환경생태복원계획 업무추진과정

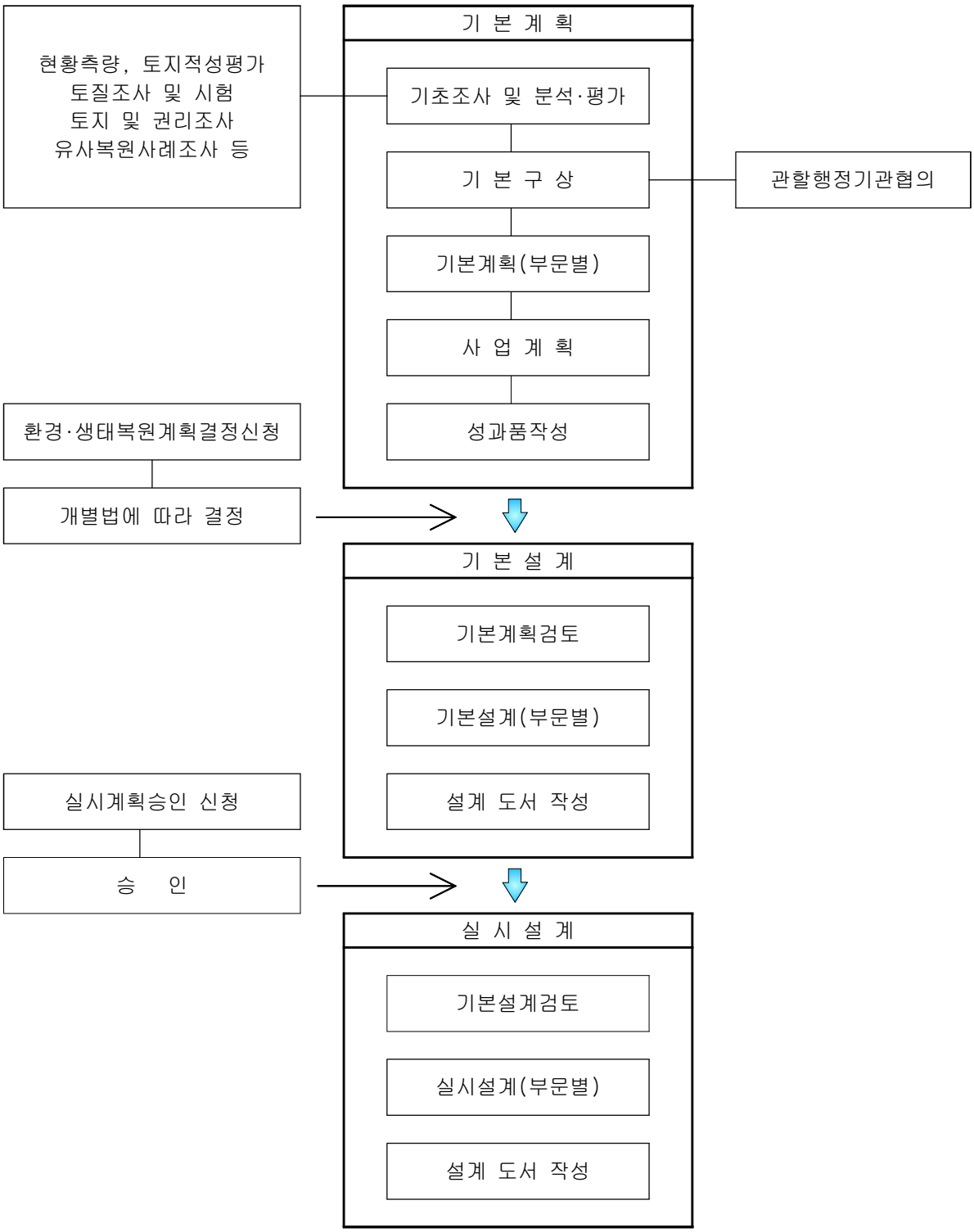

4-4 품 산정의 원단위 산정과 기준

4-4-1 표준품 산정내역

○ 표준품 산정의 기준이 되는 비목은 제1장 총칙에서 제시한 비목을 중심으로 하였으며, 이는 환경 생태복원계획에 필요한 사항만을 대상으로 한다.

○ 표준품 산정의 기본이 되는 직접인건비 품의 작업항목별 보할은 업무의 난이도를 감안하여 설정토록 한다.

1. 조사 및 측량, 토질조사 및 시험 등의 기초조사

○ 측량, 토질조사, 토지적성평가, 문화재지표조사 등의 품은 별도 적용한다.

2. 기본계획의 표준산정내역

종 별		내 용	세부항목	단 위	비 고
직접비	직접인건비	1.기초조사	①기반환경복원조사 ②경관생태조사 ③동식물서식처조사 ④생물종조사(7개분야) ⑤인문/사회현황조사	인·일 〃 〃 〃 〃	
		2.분석/평가	①조사결과의 도면화 ②분석/평가	〃 〃	
		3.기본구상	①계획의 목표설정 ②보호/관리/이용지역설정 ③이용체계구상 ④시설종류 및 규모설정 ⑤환경/생태복원구상	〃 〃 〃 〃 〃	
		4.기본계획 (부문별)	①보호/관리/이용지역계획 ②생태복원 탐방계획 ③이용 및 시설계획 ④환경생태복원계획	〃 〃 〃 〃	
		5.사업계획	①사업투자비계획 ②관리운영계획	〃 〃	
		6.성과품 작성	①보고서작성 및 편집 ②관련도서작성	〃 〃	
		7.기술협의	①공청회 / 주민설명회 ②주민간담회 / 시민계획단 ③위원회 심의 지원 ④관계기관 협의	〃 〃 〃 〃	
	직접경비	여비, 인쇄비, 조감도, 회의준비비, 현장운영비 등		식	제1장 총칙참조
간접비	제경비	(직접인건비)×120%		〃	〃
	기술료	(직접인건비+제경비)×30%		〃	〃

주 : 환경생태복원계획에 관련되는 부수적인 업무인 조사, 측량, 개발타당성조사검토, 토질조사 및 시험, 토지적성평가, 각종영향검토 및 평가 등과 같은 업무는 별도의 엔지니어링활동업무로 산정한다.

3. 기본설계, 실시설계의 표준산정내역

○ 기본설계와 실시설계의 품 산정은 엔지니어링사업대가의 기준 중 건설부문 공사비요율을 적용한다.

4-4-2 산정기준

1. 계획·기준면적의 설정

○ 기준면적의 설정을 위해 기 지정된 도시공원 및 녹지에 관한 법률을 준용하여 기준면적을 산정하였다.

구 분	기준면적
자연형하천복원, 산림식생복원, 담수생태계복원, 동물서식환경복원, 비탈(인공)면 녹화계획, 사구복원, 습지복원, 생태공원, 환경공원, 종합산림생태복원, 식물원, 훼손지(토취, 광산, 자연재해)복원 등	• 10만㎡ - L=2km, 수변구역 50m

○ 계획면적은 고시된 경우는 법정계획면적을, 신설된 경우는 기본구상을 전제로 한 조사면적을 기준으로 하되, 다음의 경우에는 환경복원계획의 계획면적에 포함한다.

- 강, 바다 등을 포함하는 지역은 강, 바다 등이 시설지구로 이용될 때 계획면적에 포함함을 원칙으로 한다.
- 발주자가 환경복원계획을 추진코자 하는 기준면적을 원칙으로 한다.

2. 표준품의 산정방법

○ 표준품의 적용에 있어 기준면적과 계획면적의 차이에 따른 품 산정은 아래의 수정식에 따라 기준면적의 소요작업량을 수정하여 산정한다.

소요작업량 = 기준면적소요작업량 × 면적보정계수(α)

3. 계획안의 수정과 과업중지에 따른 산정방법

○ 계획안이 작성되고 주민공람, 의회보고, 관할 도시계획위원회보고, 중간보고 등 행정절차과정을 거쳐 계획안이 확정된 후 발주자의 산정에 의하여 계획안이 일부변경·재작업이 수행되는 경우에는 그 변경·재작업의 정도에 따라 엔지니어링사업대가의 50~100% 수준에서 비용을 추가 지급하여야 한다.

○ 과업수행 중 발주자의 사정에 따른 과업 중단으로 인해 정부 회계연도가 경과되어 현저한 비용의 차이가 발생하였을 경우에는 엔지니어링사업대가를 당해 신년도의 노임단가를 기준으로 재산정하여야 한다.

4-4-3 단위별 변화수정과 보정

1. 면적의 대소에 대한 작업량 보정계수 산정

○ 계획면적이 기준면적을 초과하거나 못 미치는 경우의 직접인력 소요작업량의 산정을 위한 면적보정계수(α)는 다음의 식에 의해 산정한다.

$$\alpha = \left(\frac{\text{계획면적}}{\text{기준면적}}\right)^{0.5} = \left(\frac{A}{10}\right)^{0.5}$$

α : 보정계수
A : 계획면적(만㎡)

계획면적별 보정계수

면적(A)		보정계수 (α)	면적(A)		보정계수 (α)	면적(A)		보정계수 (α)
만㎡	천평		만㎡	천평		만㎡	천평	
5	15.125	0.660	14		1.224	35		2.121
6		0.736	15		1.275	40		2.297
7		0.807	16		1.326	45		2.466
8		0.875	17		1.375	50	151.250	2.627
9		0.939	18		1.426	60		2.930
10	30.250	1.000	19		1.470	70		3.214
11		1.059	20	60.500	1.516	80		3.482
12		1.116	25		1.733	90		3.737
13		1.170	30		1.933	100	302.500	3.981

주 : 계획면적이 5만㎡미만인 경우에는 5만㎡의 보정계수를 적용한다.

2. 직접인건비 소요작업량 산정

○ 계획면적이 대소에 따른 직접인력 소요작업량의 산정방법은 아래와 같이 기준면적의 직능별 직접인력 소요작업량에 계획단위 보정계수(α)를 곱하여 산출한다.

구 분	기준면적 (만㎡)	총작업량(인·일)					
		기술사	특 급	고 급	중 급	초 급	보조원
환경생태 복원계획	10	32.0α	55.0α	139.0α	184.0α	187.0α	228.0α

4-5 표준단위 업무분류와 원단위

기술업무의 직능별 직접인력 소요작업량(10만㎡기준)

(단위 : 인·일/표준단위)

구 분	업무내용	표준단위	소요인력						비고
			기술사	특 급	고 급	중 급	초 급	보조원	
1.기초조사	①기반환경복원조사	10만㎡	1.0	2.0	4.3	6.6	6.0	7.8	
	②경관생태조사	10만㎡	1.0	2.0	4.3	6.6	6.0	7.8	
	③동식물서식처조사	10만㎡	3.0	6.0	12.0	18.0	15.0	16.5	
	④생물종조사(7개분야)	10만㎡	10.0	20.0	35.0	50.0	45.0	50.0	
	⑤인문/사회현황조사	10만㎡	1.0	2.0	4.4	6.8	6.0	7.9	
	소 계		16.0	32.0	60.0	88.0	78.0	90.0	
2.분석/평가	①조사결과의 도면화	10만㎡	1.5	3.0	6.0	6.0	6.0	7.5	
	②분석/평가	10만㎡	1.5	3.0	6.0	6.0	6.0	7.5	
	소 계		3.0	6.0	12.0	12.0	12.0	15.0	
3.기본구상	①계획의 목표설정	10만㎡	0.5	0.7	4.2	5.6	6.1	8.0	
	②보호/관리/이용지역설정	10만㎡	0.7	1.4	4.2	6.6	6.1	8.0	
	③이용체계구상	10만㎡	0.7	1.4	5.2	6.6	7.6	8.0	
	④시설종류 및 규모설정	10만㎡	0.5	0.7	5.2	5.6	7.6	8.0	
	⑤환경/생태복원구상	10만㎡	0.6	0.8	4.2	5.6	7.6	8.0	
	소 계		3.0	5.0	23.0	30.0	35.0	40.0	
4.기본계획 (부문별)	①보호/관리/이용지역계획	10만㎡	1.0	1.5	7.0	8.8	7.2	12.6	
	②생태복원 탐방계획	10만㎡	1.0	1.5	5.0	6.8	7.2	12.6	
	③이용 및 시설계획	10만㎡	1.0	1.0	5.0	6.8	7.2	12.6	
	④환경생태복원계획	10만㎡	2.0	2.0	7.0	8.6	11.4	12.2	
	소 계		5.0	6.0	24.0	31.0	33.0	50.0	
5.사업계획	①사업투자비계획	10만㎡	2.2	2.8	10.2	9.0	12.0	12.2	
	②관리운영계획	10만㎡	1.8	2.2	6.8	8.0	11.0	10.8	
	소 계		4.0	5.0	17.0	17.0	23.0	23.0	
6.성과품 작성	①보고서작성 및 편집	10만㎡	0.8	0.8	2.0	4.0	3.6	5.0	
	②관련도서작성	10만㎡	0.2	0.2	1.0	2.0	2.4	5.0	
	소 계		1.0	1.0	3.0	6.0	6.0	10.0	
총 계			32.0	55.0	139.0	184.0	187.0	228.0	
7.기술협의	①공청회/주민설명회	1식	2.0	2.0	2.0	4.0	4.0	4.0	
	②주민간담회/시민계획단	1식	2.0	2.0	2.0	4.0	4.0	4.0	
	③위원회심의 지원	1식	2.0	2.0	2.0	4.0	4.0	4.0	
	④관계기관 협의	1식	2.0	2.0	2.0	4.0	4.0	4.0	
	소 계		8.0	8.0	8.0	16.0	16.0	16.0	

주 : ①기술협의는 2회 이내 기준이며, 횟수가 늘어날 경우 증가배수에 해당하는 작업품과 비용을 가산한다. (필요항목 선택적 적용)

②생물 종 조사는 관련법규에 의한 환경영향검토, 사전환경성검토, 환경영향평가 등에서 시행한 생물 종 조사 자료를 활용할 경우에는 본 품에서 제외한다.

③각종영향성검토 및 각종영향평가업무는 별도의 엔지니어링활동업무로 계상한다.

4-6 주요업무내용

구 분	업무내용	내 용
1.기초조사	①기반환경복원조사	•기후, 지형 및 지질, 토양 및 지하수, 수계 등 조사
	②경관생태조사	•패취, 가장자리와 경계, 코리더, 모자이크(패턴과 규모) 주연부 효과 등 조사
	③동식물서식처조사	•비오톱의 유형 분류 및 가치 있는 비오톱의 도출 •서식처의 유형 분류 및 유형별 조사
	④생물종조사(7개분야)	•식물상 및 식생, 곤충, 어류, 양서·파충류, 조류, 포유류, 동물상의 자연생태계조사(2계절조사 이상)
	⑤인문/사회현황조사	•인구, 토지이용현황, 교통, 주변현황 등의 조사
2.분석·평가	①조사결과의 도면화	•비오톱의 유형구 •보전가치 높은 비오톱·동식물 서식공간·수목, 수계 •양호·불량 경관 요소
	②분석/평가	•제반현황의 종합적 분석 •잠재력 및 문제점 검토, 잠재성평가
3.기본구상	①계획의 목표설정	•목표환경, 목표생태계, 목표종군
	②보호/관리/이용지역설정	•공간구성체계설정, 공간배치구상안 작성
	③이용체계구상	•공간이용체계구상, 공간 유형에 따른 탐방 구상
	④시설종류 및 규모설정	•적정수용능력 산정, 관리·이용시설 결정
	⑤환경/생태복원구상	•생태네트워크 구상 •서식처 유형별 구상
4.기본계획	①보호/관리/이용지역계획	•자연보호구역, 경관보호구역, 생물 종 보호구역, 휴가·여가 공간 등
	②생태·복원 탐방계획	•이용탐방계획, 동선계획 등
	③이용 및 시설계획	•생태복원활동 및 도입시설 프로그램계획 •관리 및 이용·관찰 시설계획
	④환경생태복원계획	•생태기반환경, 서식처유형별 복원계획
5.사업계획	①사업투자비계획	•개략공사비산정 •공종별·재원별·단계별·연차별 투자계획
	②관리운영계획	•환경·생태보전방안 제시 •관리체계 및 운영계획

4-7 표준성과품

성과구분	표준성과도서			비 고
	구 분	규 격	제출부수	
현황도	•위치도 •생태경관분석도 •주요 동식물 서식처 조사도 •종합분석도	1/50,000~1/25,000 〃 〃 〃	1부 〃 〃 〃	
계획도	•환경복원 구상도 •보호·관리·이용지역계획도 •환경복원 탐방계획도 •환경복원 시설계획도 •환경·생태복원 종합계획도	1/5,000~1/1,000 〃 〃 〃 〃	1부 〃 〃 〃 〃	
보고서	•보고서 •계획관련 도서	발주자와 협의결정	발주자와 협의결정	

주 : ①제출부수 및 성과품 종류가 증가할 경우에는 증가배수에 해당하는 작업품과 비용을 가산한다.
②계획보고서, 기타 관련 자료의 규격 및 제출부수는 발주자의 협의에 의하여 비용을 산출하여 산정한다.

제5절 개발제한구역 조경설계검토 도서 작성

5-1 정 의

○ 조경설계검토도서작성은 개발제한구역 관리규정에 의한 일정한 지역의 조경 대상지에 대한 현황을 분석하고 문제점 및 잠재력을 평가하여 주변 자연환경과 조화를 이루며 가장 이상적이고 합리적인 조경설계방안을 제시하고 설계에 대한 검토, 평가, 검정하는 것을 말한다.

5-2 자료제공의 전제

○ 개발제한구역 조경설계검토 도서작성에 관한 업무에 필요한 모든 관련자료는 원칙적으로 발주자가 제공하는 것으로 하되, 발주자가 보유하지 않는 자료는 엔지니어링사업자가 수집한다.

○ 발주자가 제공하지 못하는 자료의 조사에 있어서는 그 규모·내용에 의거하여 별도의 엔지니어링사업대가를 산정하여 엔지니어링사업자가 수행하며, 관련자료의 기밀성과 광범위한 자료가 필요한 경우 조사·분석에 필요한 상당기간과 자료수집비용이 전제되어야 한다.

5-3 업무범위와 추진과정

5-3-1 업무범위

○ 사업면적이 3,300㎡이상이거나, 조경대상이 자연의 훼손이 많이 이루어지는 경우, 또는 특별히 설계의도와 시행상의 합리적인 시공여부의 타진을 필요로 할 경우의 조경설계검토도서작성을 주 엔지니어링활동 업무로 한다.

5-3-2 추진과정

○ 타부처(관계기관)와 협의나 전문가 자문 등에 소요되는 기간은 과업수행기간에서 제외하여 그 소요기간만큼 과업수행기간을 연장하여야 한다.

조경설계검토도서작성 추진과정

·자료수집 ·1차 내용 검토·협의	→	현장 조사	→	·2차 내용 검토·협의	→	·설계도 및 시방서 조서작성	→	·감리완료 통보
				↑ 보완지시				

5-4 품 산정의 원단위 산정과 기준

5-4-1 표준품 산정내역

○ 표준품 산정의 기준이 되는 비목은 제1장 총칙에서 제시한 비목을 중심으로 하였으며, 개발제한구역 조경설계 검토도서작성에 관한 업무에 필요한 사항만을 대상으로 한다.

○ 표준품 산정의 기본이 되는 직접인건비 품의 작업항목별 보할은 업무의 난이도를 감안하여 설정토록 한다.

종 별		내 용	세부항목	단 위	비 고
직접비	직접인건비	1.1차 내용검토 및 업무협의		인·일	
		2.현장조사		〃	
		3.2차 내용검토		〃	
		4.설계도서 검토 및 시방서 조서작성		〃	
		5.기술협의	①공청회 / 주민설명회 ②주민간담회 / 시민계획단 ③위원회심의 지원 ④관계기관 협의	〃 〃 〃 〃	
	직접경비	여비, 인쇄비, 조감도, 회의준비비, 현장운영비 등		식	제1장 총칙참조
간접비	제경비	직접인건비×120%		〃	〃
	기술료	(직접인건비+제경비)×30%		〃	〃

5-4-2 산정기준

1. 계획·기준면적 선정

○ 개발제한구역 조경설계검토 도서작성에 관한 업무에 있어서의 원단위 설정을 위한 기준면적은 10만㎡로 선정한다.

○ 계획면적은 과업면적을 원칙으로 한다.

2. 표준품의 산정방법

○ 표준품의 적용에 있어 위 기준면적과 계획면적의 차이에 따른 산정은 아래의 수정식에 따라 기준면적의 소요작업량을 수정하여 산정한다.

소요작업량 = 기준면적소요작업량 × 면적보정계수(α)

3. 계획안의 수정과 과업중지에 따른 산정방법

○ 계획안이 작성되고 주민의견, 의회보고 등 행정절차과정을 거쳐 계획안이 확정된 후 발주자의 사정에 의하여 계획안이 일부변경·재작업이 수행되는 경우에는 그 변경·재작업의 정도에 따라 엔지니어링사업대가의 50～100% 수준에서 비용을 추가 지급하여야 한다.

○ 과업수행 중 발주자의 사정에 따른 과업 중단으로 인해 정부 회계연도가 경과되어 현저한 비용의 차이가 발생하였을 경우에는 엔지니어링사업대가를 당해 신년도의 노임단가를 기준으로 재산정하여야 한다.

5-4-3 단위별 변화수정과 보정

1. 면적의 대소에 대한 작업량 보정계수 산정

○ 개발제한구역 조경설계검토 도서작성에 관한 업무 계획면적이 기준면적을 초과하거나 이에 못 미치는 경우의 직접인력 소요작업량의 산정을 위한 각 작업내용별 면적보정계수(α)는 다음과 같이 산정한다.

$$\alpha = \left(\frac{\text{계획면적}}{\text{기준면적}}\right)^{0.2} = \left(\frac{A}{10}\right)^{0.2}$$

α = 보정계수
A = 계획면적(만㎡)

계획단위 면적별 보정계수

면적(A)		면적보정계수 (α)	면적(A)		면적보정계수 (α)
만㎡	평		만㎡	평	
3.3	1만평	0.801	70.0		1.476
5.0		0.871	75.0		1.496
10.0		1.000	80.0		1.516
15.0		1.084	90.0		1.552
16.5	5	1.105	100.0	≒30	1.585
20.0		1.149	132.0		1.675
25.0		1.201	150.0		1.719
30.0		1.246	165.0	50	1.752
33.0	10	1.270	200.0		1.821
40.0		1.320	231.0	70	1.874
50.0		1.380	264.0		1.925
60.0		1.431	300.0		1.974
66.0	20	1.459	330.0	100	2.012

주 : 계획면적이 3.3만㎡이하인 경우에는 3.3만㎡를 기준으로 하여 산정한다.

2. 직접인건비 소요 작업량 산정

○ 계획면적의 대소에 따른 직접인력 소요작업량의 산정방법은 아래와 같이 기준면적의 직능별 직접인력 소요작업량에 계획단위 보정계수(α)를 곱하여 산출한다.

구 분	기준면적 (만㎡)	총작업량(인·일)					
		기술사	특 급	고 급	중 급	초 급	보조원
설계검토	10	1.2α	1.6α	4.0α	13.6α	6.8α	6.8α

5-5 표준단위 업무분류와 원단위

기술업무의 직능별 직접인력에 의한 소요작업량(10만㎡기준)

(단위 : 인 · 일/표준단위)

업무내용(설계검토)		표준단위	소요인력						비고
			기술사	특급	고 급	중 급	초 급	보조원	
1.1차 내용검토 및 업무협의		10만㎡	0.2	0.3	0.8	2.6	1.3	1.3	
2.현장조사		10만㎡	0.3	0.3	0.8	2.8	1.4	1.4	
3.2차 내용검토		10만㎡	0.3	0.3	0.8	2.8	1.4	1.4	
4.설계도서 검토 및 시방서 조서작성		10만㎡	0.4	0.7	1.6	5.4	2.7	2.7	
총 계			1.2	1.6	4.0	13.6	6.8	6.8	
6.기술협의	①공청회/주민설명회 ②주민간담회/시민계획단 ③위원회심의 지원 ④관계기관 협의	1식 1식 1식 1식	2.0 2.0 2.0 2.0	2.0 2.0 2.0 2.0	2.0 2.0 2.0 2.0	4.0 4.0 4.0 4.0	4.0 4.0 4.0 4.0	4.0 4.0 4.0 4.0	
	소 계		8.0	8.0	8.0	16.0	16.0	16.0	

5-6 주요업무내용

항 목	업무내용
1.1차 내용검토 및 업무협의	·위치 및 지형도의 검토 ·부지조성공사, 종·횡단면도 검토 ·토목공사계획 평면도 및 조경계획 평면도 ·조경사업계획서 ·사업목적 및 사업내용 청취 ·현장답사일시 협의 ·기타 설계 및 시방서에 필요한 사항
2.현장조사	·인문환경 : 지리적 위치 / 토지이용현황 ·자연환경 : 지형 및 지세 / 토양 / 주변식생 / 가시권
3.2차 내용검토	·현장과 설계도면과의 일치여부 ·계획도면과 지역과의 조화여부 ·계획수종의 대상지역 적응성 여부 ·계획 및 설계의 기능적 타당성 여부 ·공사내역 및 시방서의 타당성 여부
4.설계도서검토 및 시방서 조서작성	·조경사업계획서 확정 ·사업계획평면도 결정 ·사업비 산출 내역서 검토 ·시방서 조서 작성 ·기 타

5-7 표준성과품

○ 보고서 작성 및 기타 (발주자와 협의 결정)

제11장 사업관리

제1절 사업타당성 조사분석업무

제2절 농지전용

제3절 산지전용

제4절 총괄계획관리

제5절 계획관리

제6절 사후관리계획

제7절 도시계획 퍼실리테이션

제1절 사업타당성 조사분석업무

1-1 정 의

○ 사업에 대한 타당성 조사·분석업무는 주어진 부지를 대상으로 무엇을 개발하여야 할 것인가를 판단하는 데 필요한 조사·분석, 진단과정을 말한다.

○ 즉, 어느 발주자가 주어진 토지를 놓고 어떤 용도로 사용함이 적절하며, 사업성 전망이 있을 것인가 하는 의뢰를 해왔을 때, 조사·분석과정을 통한 대안을 제시해 주는 작업이다. 토지의 조사·분석은 그 대상과 목적에 따라 조사의 정도가 달라지나, 일반적으로 자연환경조사 분석과 인문환경조사·분석 및 이에 수반되어 실시되는 현지측량 및 주변여건 조사 등이 포함된다.

1-2 자료제공의 전제

○ 사업타당성 조사·분석에 필요한 모든 관련자료는 원칙적으로 발주자가 제공하는 것으로 하되, 발주자가 제공하지 않는 자료는 엔지니어링사업자가 수집한다.

○ 발주자가 제공하지 못하는 자료의 조사에 있어서는 그 규모·내용에 의거하여 별도의 엔지니어링사업대가를 산정하여 엔지니어링사업자가 수행하며, 당해 관련자료의 기밀성과 광범위한 자료가 요구되는 경우 조사·분석에 필요한 상당기간과 자료수집비용이 전제되어야 한다.

1-3 업무범위와 추진과정

1-3-1 업무범위

○ 주어진 부지에 대한 각종의 조사, 연구 및 사업에 필요한 기본적 조사, 분석, 진단의 실시를 통하여 사업에 관한 기초이론을 전개, 제시하고 기본방향을 정립한다.

○ 조사·분석업무의 품 산정은 도시개발부문과 지역개발부문으로 구분하여 산정하며, 각각의 업무범위는 도시개발부문은 시가지 내 일정토지에 대한 타당성 조사·분석 및 분석업무를 말하며, 지역개발부문은 시가지 외 지역에서의 타당성 조사·분석사업을 말한다.

1. 도시개발부문

○ 본 품셈에서 적용하는 대상사업은 도시지역내 주거지역, 상업지역, 공업지역과 비도시지역내 계획관리지역 대상으로 하는 시가지개발 사업부문과 도시시설 개발부문으로 구분하여 산정하며 유사한 업무에 대해서는 이를 준용·적용토록 한다.

도시개발부문의 업무범위

구 분	대상사업	비 고
시가지 개발사업	·주거, 상업, 공업 등의 시가지 개발 사업 ·도시재생 사업 ·역세권 개발사업 등	
도시시설 개발	·소규모 필지 단위 개발 ·이전적지(移轉適地)개발 ·미개발지 활용계획 ·재건축 등의 건축계획 ·도시·군계획시설 사업 및 이와 유사한 시설에 대한 타당성 검토	건축계획이 수반되는 경우로서 건축 계획수립에 필요한 작업은 별도로 한다.

2. 지역개발부문

○ 지역개발부문은 도시지역내 자연녹지지역과 비도시지역(계획관리지역 제외)을 대상으로 주택단지, 산업단지, 물류단지, 관광지등 일정면적 이상의 단위개발사업과 고속도로 연변개발, 철도역사 주변개발 등 주요간선시설 주변의 개발사업 등이 있으며 유사업무는 본 품셈을 적용하여 작성토록 한다.

○ 업무범위는 현황조사·분석, 개발규모 및 내용설정, 기본구상안 작성, 타당성검토, 사업집행계획, 성과품작성 등을 엔지니어링활동범위로 한다.

1-3-2 추진과정

○ 타부처(관계기관)와 협의나 전문가 자문 등에 소요되는 기간은 과업수행기간에서 제외하여 그 소요기간만큼 과업수행기간을 연장하여야 한다.

사업타당성 조사·분석 업무 추진과정

1-4 품 산정의 원단위 산정과 기준

1-4-1 표준품 산정내역

○ 표준품 산정의 기준이 되는 비목은 제1장 총칙에서 제시한 비목을 중심으로 하였으며, 사업타당성 조사·분석업무에 필요한 사항만을 대상으로 한다.

○ 표준품 산정의 기준이 되는 직접인건비 품의 작업항목별 보할은 업무의 난이도를 감안하여 설정토록 한다.

1. 도시개발부문

종 별		내 용	세부항목	단 위	비 고
직접비	직접인건비	1.조사·분석	①현황조사 ②분석, 평가, 진단	인·일 〃	
		2.기본구상	①기본구상 ②타당성검토 및 경제성검토	〃 〃	
		3.성과품작성	①성과품작성	〃	
		4.기술협의	①공청회 / 주민설명회 ②주민간담회 / 시민계획단 ③위원회 심의 지원 ④관계기관 협의	〃 〃 〃 〃	
	직접경비	여비, 인쇄비, 조감도, 회의준비비 현장운영비 등		식	제1장 총칙참조
간접비	제경비	(직접인건비)×110%		〃	〃
	기술료	(직접인건비+제경비) ×25%		〃	〃

주 : 측량, 토질조사 및 시험은 별도 관련품을 적용한다.

2. 지역개발부문

종 별		내 용	세부항목	단위	비 고
직접비	직접인건비	1.조사·분석	①현황조사·분석	인·일	
		2.기본구상	①개발규모 및 내용설정 ②기본구상안 작성 ②타당성검토	〃 〃 〃	
		3.실행계획	①사업집행계획	〃	
		4.성과품작성	①성과품작성	〃	
		5.기술협의	①공청회 / 주민설명회 ②주민간담회 / 시민계획단 ③위원회심의 지원 ④관계기관 협의	〃 〃 〃 〃	
	직접경비	여비, 인쇄비, 조감도, 회의준비비, 현장운영비 등		식	제1장 총칙참조
간접비	제경비	(직접인건비)×110%		〃	〃
	기술료	(직접인건비+제경비) ×25%		〃	〃

주 : 측량, 토질조사 및 시험은 별도 관련품을 적용한다.

1-4-2 산정기준

1. 계획·기준면적의 설정

○ 사업타당성 조사·분석업무 원단위 설정을 위한 기준면적을 도시개발부문 중 시가지개발 사업은 10만㎡, 도시시설개발사업은 3만㎡로, 지역개발부문은 50만㎡로 산정하였다.

구 분		기준면적
도시개발부문	·시가지개발사업	10만㎡
	·도시시설개발	3만㎡
지역개발부문		50만㎡

○ 계획면적은 타당성조사·분석업무 과업면적을 원칙으로 한다.

2. 표준품의 산정방법

○ 표준품의 적용에 있어 기준면적과 계획면적의 차이에 따른 산정은 아래의 수정식에 따라 기준면적의 소요작업량을 수정하여 산정한다.

○ 소요작업량 = 기준면적소요작업량 × 면적보정계수(α) × 과업밀도보정계수(β) × 난이도보정계수(γ)

3. 계획안의 수정과 과업중지 등에 따른 산정방법

○ 계획안이 작성되고 중간 및 최종보고 등의 업무수행절차과정을 거치거나 또는 주민공람, 의회보고 등 행정절차과정을 거쳐 계획안이 확정된 후 발주자의 사정에 의하여 계획안이 일부변경·재작업이 수행되는 경우에는 그 변경·재작업의 정도에 따라 엔지니어링사업대가의 50～100% 수준에서 비용을 추가 지급하여야 한다.

○ 과업수행 중 발주자의 사정에 따른 과업 중단으로 인해 정부 회계연도가 경과되어 현저한 비용의 차이가 발생하였을 경우에는 엔지니어링사업대가를 당해 신년도의 노임단가를 기준으로 재산정하여야 한다.

1-4-3 단위별 변화수정과 보정

1. 작업량 보정계수 산정

1) 면적의 대소에 대한 작업량 보정계수 산정

○ 계획면적이 기준면적을 초과하거나 못 미치는 경우의 직접인력 소요작업량의 산정을 위한 면적보정계수(α)는 다음의 식에 의해 산정한다.

도시 개발 부문	시가지개발사업	$\alpha = (\frac{계획면적}{기준면적})^{0.6} = (\frac{A}{10})^{0.6}$	α : 보정계수 A : 계획면적 (만㎡)
	도시시설개발	$\alpha = (\frac{계획면적}{기준면적})^{0.8} = (\frac{A}{3})^{0.8}$	
지역개발부문		$\alpha = (\frac{계획면적}{기준면적})^{0.5} = (\frac{A}{50})^{0.5}$	

계획단위 면적별 보정계수

면 적 (A) 만㎡	도시개발부문		지역개발부문 (α)	비고
	시가지개발사업(α)	도시시설개발사업(α)		
3.0	0.486	1.000	0.447	
5.0	0.660	1.505	0.447	
10.0	1.000	2.620	0.447	
20.0	1.516	4.562	0.632	
30.0	1.933	6.310	0.775	
40.0	2.297	7.942	0.894	
50.0	2.627	9.495	1.000	
60.0	2.930	10.986	1.095	
70.0	3.214	12.427	1.183	
80.0	3.482	13.828	1.265	
90.0	3.737	15.195	1.342	
100.0	3.981	16.531	1.414	

주 : ①도시개발부문의 계획면적이 3만㎡미만인 경우에는 계획면적 3만㎡를 기준으로 하여 산정한다.
②지역개발부문의 계획면적이 10만㎡미만인 경우에는 계획면적 10만㎡를 기준으로 하여 산정한다.

2) 과업밀도에 대한 작업량 보정계수 산정

○ 시가화밀도가 높아 상세한 타당성조사 및 분석이 요구되는 경우 다음의 과업밀도 보정계수(β)를 적용한다.

구 분	대상범위와 조건의 복잡성 정도	과업밀도 보정계수(β)
시가지 개발사업	시가지조성사업, 도시재생사업, 역세권개발사업 등 개별법에서 정하는 토지이용계획을 수반하는 경우	1.0
	시가지조성사업, 도시재생사업, 역세권개발사업 등 개별법에서 정하는 토지이용계획을 수반하고 상업·업무·공업 등 단지개발사업의 사업아이템이나 유치시설 등에 관해 구체적인 타당성 검토가 필요한 경우	1.2
도시시설 개발	재건축, 이전적지개발, 도시·군계획시설사업 (시장, 유통시설 등) 등과 같이 구체적인 건축계획이 수반되고 단일용도(주용도, 부용도)의 개발인 경우	1.2
	재건축, 이전적지개발, 도시·군계획시설사업 (시장, 유통시설 등) 등과 같이 구체적인 건축계획이 수반되고 입체·복합개발이 필요한 경우	1.4

3) 분석의 난이도에 대한 작업량 보정계수 산정

○ 업종/업태별 경쟁구조분석, 마케팅 리서치, 수요예측 및 규모설정을 통해 투자계획 및 재무적 타당성을 검토함에 있어 다양하고 난이도가 있는 타당성분석기법을 도입할 경우 난이도 보정계수(γ)를 적용하여 산정한다.

구 분	난이도의 정도	난이도 보정계수(γ)
타당성 분석	리스크분석, 비용-수입분석, 손익분석, 투자수익분석, 추정현금흐름표작성 등 경제적 타당성 검토에 있어 난이도가 높을 경우	1.2 - 1.5

주 : 재무적 타당성 등의 검토가 외부 전문기관의 참여가 필요한 경우는 별도 관련품을 적용한다.

2. 직접인건비 소요 작업량 산정

○ 계획면적의 대소에 따른 직접인력 소요작업량의 산정방법은 아래와 같이 기준면적의 직능별 직접인력 소요작업량에 계획단위 면적보정계수(α, β, γ)을 곱하여 산출한다.

구 분	기준 면적 (만㎡)	총작업량 (인·일)					
		기술사	특 급	고 급	중 급	초 급	보조원
시가지개발사업	10	16.7αβγ	33.4αβγ	49.5αβγ	59.8αβγ	66.6αβγ	69.4αβγ
도시시설개발	3	12.6αβγ	25.2αβγ	38.4αβγ	51.2αβγ	52.1αβγ	41.6αβγ
지역개발부문	50	14.0αβγ	28.0αβγ	50.3αβγ	71.6αβγ	80.9αβγ	80.7αβγ

1-5 표준단위 업무분류와 원단위

1-5-1 도시개발부문(시가지개발사업)

기술업무의 직능별 직접인력 소요작업량 (면적 10만㎡ 기준)

(단위 : 인·일/표준단위)

구 분	업무내용	표준단위	소요인력						비고
			기술사	특급	고급	중급	초급	보조원	
1.조사분석	①현황조사	10만㎡	0.8 (1.6)	1.8 (3.6)	4.4 (8.8)	9.3 (18.6)	14.3 (28.6)	20.2 (40.4)	주1
	②분석, 평가, 진단	10만㎡	3.3	6.2	10.5	15.1	13.2	10.2	
2.기본구상	①기본구상	10만㎡	7.6	17.9	18.5	12.0	11.3	8.3	
	②타당성검토 및 경제성검토	10만㎡	4.3	6.1	10.5	15.1	13.2	10.2	
3.성과품작성	①성과품작성	10만㎡	0.7	1.4	5.6	8.3	14.6	20.5	
총 계			16.7 (17.5)	33.4 (35.2)	49.5 (53.9)	59.8 (69.1)	66.6 (80.9)	69.4 (89.6)	주1
4.기술협의	①공청회/주민설명회	1식	2.0	2.0	2.0	4.0	4.0	4.0	주2
	②주민간담회/시민계획단	1식	2.0	2.0	2.0	4.0	4.0	4.0	
	③위원회심의 지원	1식	2.0	2.0	2.0	4.0	4.0	4.0	
	④관계기관 협의	1식	2.0	2.0	2.0	4.0	4.0	4.0	
	소 계		8.0	8.0	8.0	16.0	16.0	16.0	

주 : ①(　)안의 품은 마케팅조사 및 수요예측 등의 추가 업무가 있는 경우 적용한다.

②기술협의는 2회 이내 기준이며, 횟수가 늘어날 경우 증가배수에 해당하는 작업품과 비용을 가산한다. (필요항목 선택적 적용)

1-5-2 도시개발부문(도시시설개발)

기술업무의 직능별 직접인력 소요작업량(면적 3만㎡ 기준)

(단위 : 인·일/표준단위)

구 분	업무내용	표준단위	소요인력						비고
			기술사	특급	고급	중급	초급	보조원	
1.조사분석	①현황조사	3만㎡	0.5 (1.0)	1.3 (2.6)	3.4 (6.8)	7.9 (15.8)	10.0 (20.0)	15.3 (30.6)	주1
	②분석, 평가, 진단	3만㎡	2.9	6.8	9.5	10.0	10.6	-	
2.기본구상	①기본구상	3만㎡	5.5	10.4	12.5	12.7	12.2	9.7	
	②타당성검토 및 경제성검토	3만㎡	3.2	5.7	10.6	11.2	8.2	2.1	
3.성과품작 성	①성과품작성	3만㎡	0.5	1.0	2.4	9.4	11.1	14.5	
총 계			12.6 (13.1)	25.2 (26.5)	38.4 (41.8)	51.2 (59.1)	52.1 (62.1)	41.6 (56.9)	주1
4.기술협의	①공청회/주민설명회	1식	2.0	2.0	2.0	4.0	4.0	4.0	주2
	②주민간담회/시민계획단	1식	2.0	2.0	2.0	4.0	4.0	4.0	
	③위원회심의 지원	1식	2.0	2.0	2.0	4.0	4.0	4.0	
	④관계기관 협의	1식	2.0	2.0	2.0	4.0	4.0	4.0	
	소 계		8.0	8.0	8.0	16.0	16.0	16.0	

주 : ①(　)안의 품은 마케팅조사 및 수요예측 등의 추가 업무가 있는 경우 적용한다.

②기술협의는 2회 이내 기준이며, 횟수가 늘어날 경우 증가배수에 해당하는 작업품과 비용을 가산한다. (필요항목 선택적 적용)

1-5-3 지역개발부문

기술업무의 직능별 직접인력 소요작업량(면적 50만㎡ 기준)

(단위 : 인·일/표준단위)

구 분	업무내용	표준단위	소요인력						비고
			기술사	특급	고급	중급	초급	보조원	
1.조사·분석	①현황조사·분석	50만㎡	0.7 (1.4)	1.8 (3.6)	5.2 (10.4)	16.6 (33.2)	21.0 (42.0)	27.4 (54.8)	주1
2.기본구상	①개발규모 및 내용설정 ②기본구상안 작성 ③타당성검토	50만㎡ 50만㎡ 50만㎡	2.9 6.0 3.3	6.8 10.5 5.2	10.8 16.9 9.5	12.5 20.8 10.2	10.1 20.3 9.3	- 19.4 9.1	
3.실행계획	①사업집행계획	50만㎡	0.7	3.1	5.5	6.5	8.6	6.5	
4.성과품작성	①성과품작성	50만㎡	0.4	0.6	2.4	5.0	11.6	18.3	
총 계			14.0 (14.7)	28.0 (29.8)	50.3 (55.5)	71.6 (88.2)	80.9 (101.9)	80.7 (108.1)	주1
5.기술협의	①공청회/주민설명회 ②주민간담회/시민계획단 ③위원회심의 지원 ④관계기관 협의	1식 1식 1식 1식	2.0 2.0 2.0 2.0	2.0 2.0 2.0 2.0	2.0 2.0 2.0 2.0	4.0 4.0 4.0 4.0	4.0 4.0 4.0 4.0	4.0 4.0 4.0 4.0	주2
	소 계		8.0	8.0	8.0	16.0	16.0	16.0	

주 : ①(　)안의 품은 마케팅조사 및 수요예측 등의 추가 업무가 있는 경우 적용한다.

②기술협의는 2회 이내 기준이며, 횟수가 늘어날 경우 증가배수에 해당하는 작업품과 비용을 가산한다. (필요항목 선택적 적용)

1-6 주요업무내용

1-6-1 도시개발부문

구 분	업무내용
1. 조사·분석	·자연환경(식생, 지형, 지질, 수계 등), 인문환경(인구, 시설, 교통 등) ·기타 사회 환경 등 ·부지조건분석, 사업성 검토, 사업조건설정 등
2. 기본구상	·사업방향설정, 기본구상 작성 등 ·기술적, 경제적 타당성(개략사업비산정, 투자수익 분석) 검토

1-6-2 지역개발부문

구 분	업무내용
1. 조사·분석	·자연환경, 인문환경, 사회경제환경 조사, 기존 및 상위계획 검토
2. 기본구상	·인구규모설정, 시설별 수요산정, 개발규모 및 지표설정, 입지여건분석 및 사업성 검토 ·사업방향설정, 지역관련성검토, 공간구성구상, 토지이용구상, 동선체계구상, 녹지체계구상 ·기술적, 경제적 타당성(개략사업비산정, 투자수익 분석)검토
3. 실행계획	·연차별 개발계획, 운영관리계획

1-7 표준성과품

성과구분	표준성과도서			비 고
	구 분	규 격	제출부수	
보고서	·타당성검토보고서	발주자와 협의결정	1부	
관련도서	·현황분석도 ·개발구상도	발주자와 협의결정	1부 〃	
기타자료		발주자와 협의결정	발주자와 협의결정	

주 : ①제출부수 및 성과품 종류가 증가할 경우에는 증가배수에 해당하는 작업품과 비용을 가산한다.
②계획보고서 및 기타 관련자료의 규격 및 제출부수는 발주자와의 협의에 의하여 비용을 산정한다.

제2절 농지전용

2-1 정 의

○ 농지전용에 관한 업무라 함은 각종 지역 및 도시계획업무와 관련하여 농지법에 의한 농지분야협의, 농지전용협의 또는 농지전용허가 등을 득하기 위하여 필요로 하는 제반 검토 분석 및 이에 필요한 도서작성업무를 말한다.

2-2 자료제공의 전제

○ 농지전용에 관한 업무에 필요한 모든 계획, 설계 등 관련자료는 원칙적으로 발주자가 제공하는 것으로 하되, 발주자가 보유하지 않는 자료는 엔지니어링활동주체가 수집한다.

○ 발주자가 제공하지 못하는 자료의 조사에 있어서는 그 규모·내용에 의거하여 별도의 엔지니어링사업대가를 산정하여 엔지니어링활동주체가 수행하며, 관련자료의 기밀성과 광범위한 자료가 필요한 경우 조사·분석에 필요한 상당기간과 자료수집비용이 전제되어야 한다.

2-3 업무범위와 추진과정

2-3-1 업무범위

○ 농지전용업무의 범위는 농지전용을 필요로 하는 대상토지와 관련하여 농지분야협의, 농지전용 허가 또는 협의 등을 득하기 위해서 갖추어야 할 제반도서 가운데 엔지니어링활동주체의 기술적 능력이 요구되는 부분을 작성한다.

2-3-2 추진과정

○ 타부처(관계기관)와 협의나 전문가 자문 등에 소요되는 기간은 과업수행기간에서 제외하여 그 소요기간만큼 과업수행기간을 연장하여야 한다.

농지전용에 관한 업무추진절차

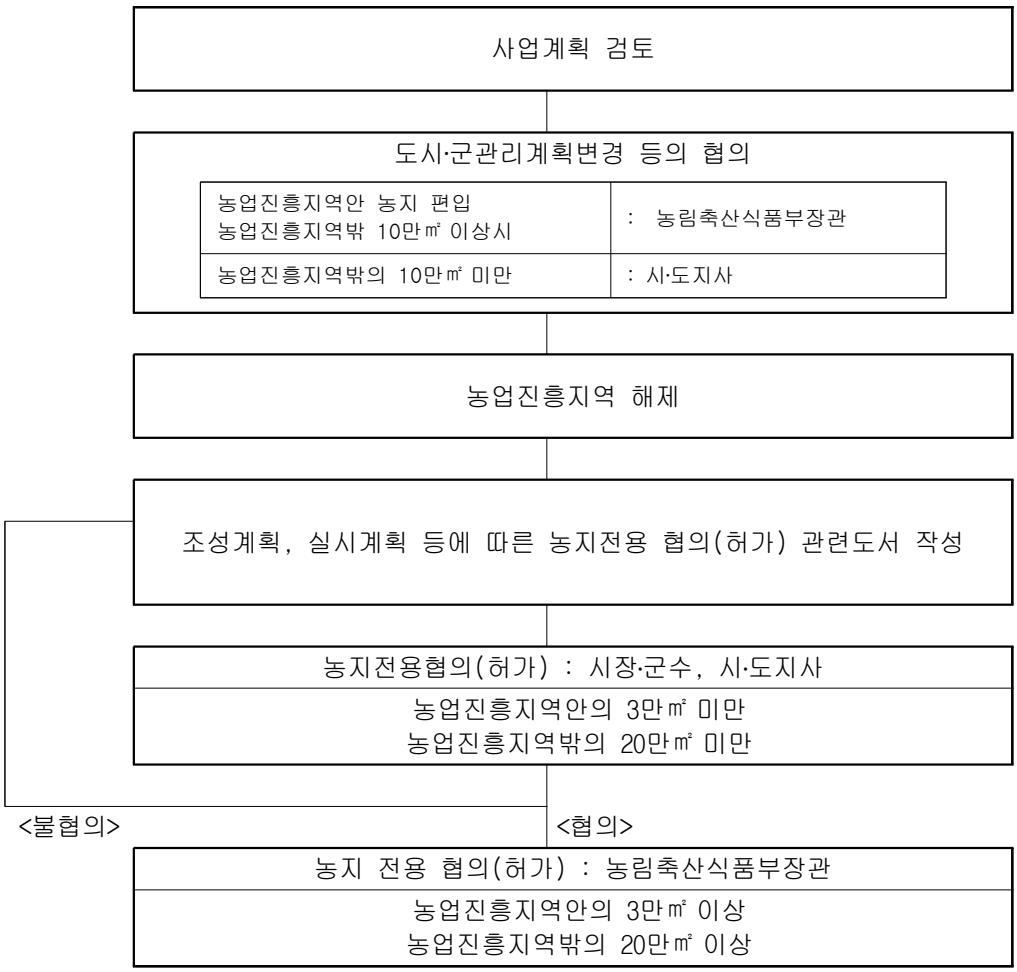

2-4 품 산정의 원단위 산정과 기준

2-4-1 표준품 산정내역

○ 표준품 산정의 기준이 되는 비목은 제1장 총칙에서 제시한 비목을 중심으로 하였으며, 농지전용업무에 필요한 사항만을 대상으로 한다.

○ 표준품 산정의 기본이 되는 직접인건비 품의 작업항목별 보할은 업무의 난이도를 감안하여 설정토록 한다.

종 별		내 용	세부항목	단위	비 고
직접비	직접인건비	1.계획안 검토	①관련법규 검토 ②관련계획 검토 ③주변지역과의 상관성검토	인·일 〃 〃	
		2.농지전용 도서작성	①농지전용협의(허가)요청서 작성 ②농지편입 현황조서 작성 ③피해방지계획서 작성 ④도시계획 관련도서 작성 ⑤농지관련 도서 작성 ⑥초지관련 도서 작성	〃 〃 〃 〃 〃 〃	
		3.기술협의	①공청회 / 주민설명회 ②주민간담회 / 시민계획단 ③위원회 심의 지원 ④관계기관 협의	〃 〃 〃 〃	
	직접경비	여비, 인쇄비, 조감도, 회의준비비, 현장운영비 등		식	제1장 총칙참조
간접비	제경비	(직접인건비)×110%		〃	〃
	기술료	(직접인건비+제경비)×20%		〃	〃

1-4-2 산정기준

1. 계획·기준면적 선정

○ 농지전용관련업무에 있어서의 원단위 설정을 위한 기준면적은 50만㎡로 선정한다.

○ 계획면적은 과업면적을 원칙으로 한다.

2. 표준품의 산정방법

○ 표준품의 적용에 있어 위 기준면적과 계획면적의 차이에 따른 산정은 아래의 수정식에 따라 기준면적의 소요작업량을 수정하여 산정한다.

○ 소요작업량 = 기준면적소요작업량 × 면적보정계수(α)

3. 계획안의 수정과 과업중지 등에 따른 산정방법

○ 계획안이 작성되고 주민의견, 의회보고 등 행정절차과정을 거쳐 계획안이 확정된 후 발주자의 사정에 의하여 계획안이 일부변경·재작업이 수행되는 경우에는 그 변경·재작업의 정도에 따라 엔지니어링사업대가의 50～100% 수준에서 비용을 추가 지급하여야 한다.

○ 과업수행 중 발주자의 사정에 따른 과업 중단으로 인해 정부 회계연도가 경과되어 현저한 비용의 차이가 발생하였을 경우에는 엔지니어링사업대가를 당해 신년도의 노임단가를 기준으로 재산정하여야 한다.

○ 도시·군관리계획 등 농지분야 협의는 별도의 엔지니어링활동 업무로 계상한다.

○ 농업진흥지역해제업무가 농지전용허가와 동시에 이루어지는 경우에는 단일업무로 계상한다.

○ 농지전용협의와 농지전용허가가 동시에 이루어지는 경우에는 단일업무로 계상한다.

1-4-3 단위별 변화수정과 보정

1. 면적의 대소에 대한 작업량 보정계수 산정

○ 농지전용에 관한 업무 계획면적이 기준면적을 초과하거나 이에 못 미치는 경우의 직접인력 소요작업량의 산정을 위한 각 작업내용별 면적보정계수(α)는 다음과 같이 산정한다.

$$\alpha = \left(\frac{\text{계획면적}}{\text{기준면적}}\right)^{0.5} = \left(\frac{A}{50}\right)^{0.5}$$

α = 보정계수
A = 계획면적(만㎡)

계획단위 면적별 보정계수

계획면적(만㎡)	보정계수(α)	계획면적(만㎡)	보정계수(α)
10	0.447	70	1.183
20	0.632	100	1.414
30	0.775	150	1.732
40	0.894	200	2.000
50	1.000	300	2.449

주 : 계획면적이 10만㎡미만인 경우에는 계획면적 10만㎡를 기준으로 하여 산정한다.

2. 직접인건비 소요 작업량 산정

○ 계획면적의 대소에 따른 직접인력 소요작업량의 산정방법은 아래와 같이 기준면적의 직능별 직접인력 소요작업량에 계획단위 보정계수(α)를 곱하여 산출한다.

구 분	기준면적 (만㎡)	총작업량 (인·일)					
		기술사	특 급	고 급	중 급	초 급	보조원
농지전용	50	1.1α	4.9α	12.2α	17.7α	33.3α	38.6α

2-5 표준단위 업무분류와 원단위

기술업무의 직능별 직접인력에 의한 소요작업량 (50만㎡ 기준)

(단위 : 인·일/표준단위)

구 분	업무내용	표준단위	소요인력						비고
			기술사	특급	고급	중급	초급	보조원	
1. 계획안검토	①관련법규 검토	50만㎡	0.1	0.2	0.3	0.5	0.9	1.0	
	②관련계획 검토	50만㎡	0.1	0.2	0.3	0.5	0.9	1.0	
	③주변지역과의 상관성 검토	50만㎡	0.1	0.2	0.5	0.7	1.2	1.5	
	소 계		0.3	0.6	1.1	1.7	3.0	3.5	
2. 농지전용 도서작성	①농지전용협의 요청서 작성	50만㎡	0.4	0.7	1.4	2.0	3.8	4.3	
	②농지편입현황조서 작성	50만㎡	-	0.8	4.1	6.0	11.3	13.0	
	③피해방지계획서 작성	50만㎡	0.4	0.7	1.4	2.0	3.8	4.3	
	④도시계획 관련도서 작성	50만㎡	-	0.7	1.4	2.0	3.8	4.5	
	⑤농지 관련도서 작성	50만㎡	-	0.7	1.4	2.0	3.8	4.5	
	⑥초지 관련도서 작성	50만㎡	-	0.7	1.4	2.0	3.8	4.5	
	소 계		0.8	4.3	11.1	16.0	30.3	35.1	
총 계			1.1	4.9	12.2	17.7	33.3	38.6	
3.기술협의	①공청회/주민설명회	1식	2.0	2.0	2.0	4.0	4.0	4.0	주1
	②주민간담회/시민계획단	1식	2.0	2.0	2.0	4.0	4.0	4.0	
	③위원회심의 지원	1식	2.0	2.0	2.0	4.0	4.0	4.0	
	④관계기관 협의	1식	2.0	2.0	2.0	4.0	4.0	4.0	
	소 계		8.0	8.0	8.0	16.0	16.0	16.0	

주 : 기술협의는 2회 이내 기준이며, 횟수가 늘어날 경우 증가배수에 해당하는 작업품과 비용을 가산한다. (필요항목 선택적 적용)

2-6 주요업무내용

구 분	업무내용	내 용
1.계획안검토	①관련법규 검토	·농지전용에 필요한 관계법 검토
	②관련계획 검토	·농지전용과 관련된 상위 및 관련계획검토
	③주변지역과의 상관성 검토	·당해 지역과 주변지역 관련사항
2. 농지전용 도서작성	①농지전용협의 요청서 작성	·농지전용협의 요청서 작성 (입안사유, 심사의견서)
	②농지편입 현황조서 작성	·시가화지역 또는 도시·군계획시설 부지로 변경되는 지역의 농지 지목별 토지조서 작성
	③피해방지계획서 작성	·농업경영과 농어촌생활환경에 피해가 예상되는 경우 피해종류별 필요한 피해방지계획 작성
	④도시계획관련도서 작성	·도시·군기본계획 또는 도시·군관리계획안 ·용도지역 현황조서 ·인구밀도 현황조서
	⑤농지 관련도서 작성	·농지조성비 납부조치 확약서 작성 ·농지개량조합 수해지역내의 편입농지조서 및 도면작성 ·사실상 농지편입여부 및 편입시 조서작성 ·편입농지의 농업생산기반정비(계획)현황 작성 ·농지전용 협의도 작성
	⑥초지 관련도서 작성	·초지법에 의해 조성된 편입초지 현황조서 및 도면작성

2-7 표준성과품

성과구분	표준성과도서			비 고
	구 분	규 격	제출부수	
농지전용 도서	1.사업(개발)계획서 및 농지 전용협의 요청서	1 식	3부	계획안 요약 (입안사유, 심사의견서)
	2.편입토지 및 현황계획조서	1/5,000~1/25,000	3부	도시계획관련, 농지, 초지
	3.농지전용 협의도		3부	도시계획관련, 농지, 초지
	4.피해방지계획서		3부	

주 : 제출부수 및 성과품 종류가 증가할 경우에는 증가배수에 해당하는 작업품과 비용을 가산한다.

제3절 산지전용

3-1 정 의

○ 산지전용에 관한 업무라 함은 각종 지역 및 도시계획업무와 관련하여 산지관리법에 의한 지역·지구 및 구역 등의 지정·결정 협의, 산지전용협의 또는 산지전용허가 등을 득하기 위하여 필요로 하는 제반 검토 분석 및 이에 필요한 도서작성업무를 말한다

3-2 자료제공의 전제

○ 산지전용에 관한 업무에 필요한 모든 계획, 설계 등 관련자료는 원칙적으로 발주자가 제공하는 것으로 하되, 발주자가 보유하지 않는 자료는 엔지니어링사업자가 수집한다.

○ 발주자가 제공하지 못하는 자료의 조사에 있어서는 그 규모·내용에 의거하여 별도의 엔지니어링사업대가를 산정하여 엔지니어링사업자가 수행하며, 관련자료의 기밀성과 광범위한 자료가 필요한 경우 조사·분석에 필요한 상당기간과 자료수집비용이 전제되어야 한다.

3-3 업무범위와 추진과정

3-3-1 업무범위

○ 산지전용업무의 범위는 산지전용을 필요로 하는 대상토지와 관련하여 지역·지구 및 구역 등의 지정·결정 협의, 산지전용 협의 또는 허가 등을 득하기 위해서 갖추어야 할 제반도서 가운데 엔지니어링사업자의 기술적 능력이 요구되는 부분을 작성한다.

3-3-2 추진과정

○ 타부처(관계기관)와 협의나 전문가 자문 등에 소요되는 기간은 과업수행기간에서 제외하여 그 소요기간만큼 과업수행기간을 연장하여야 한다.

산지전용에 관한 업무추진절차

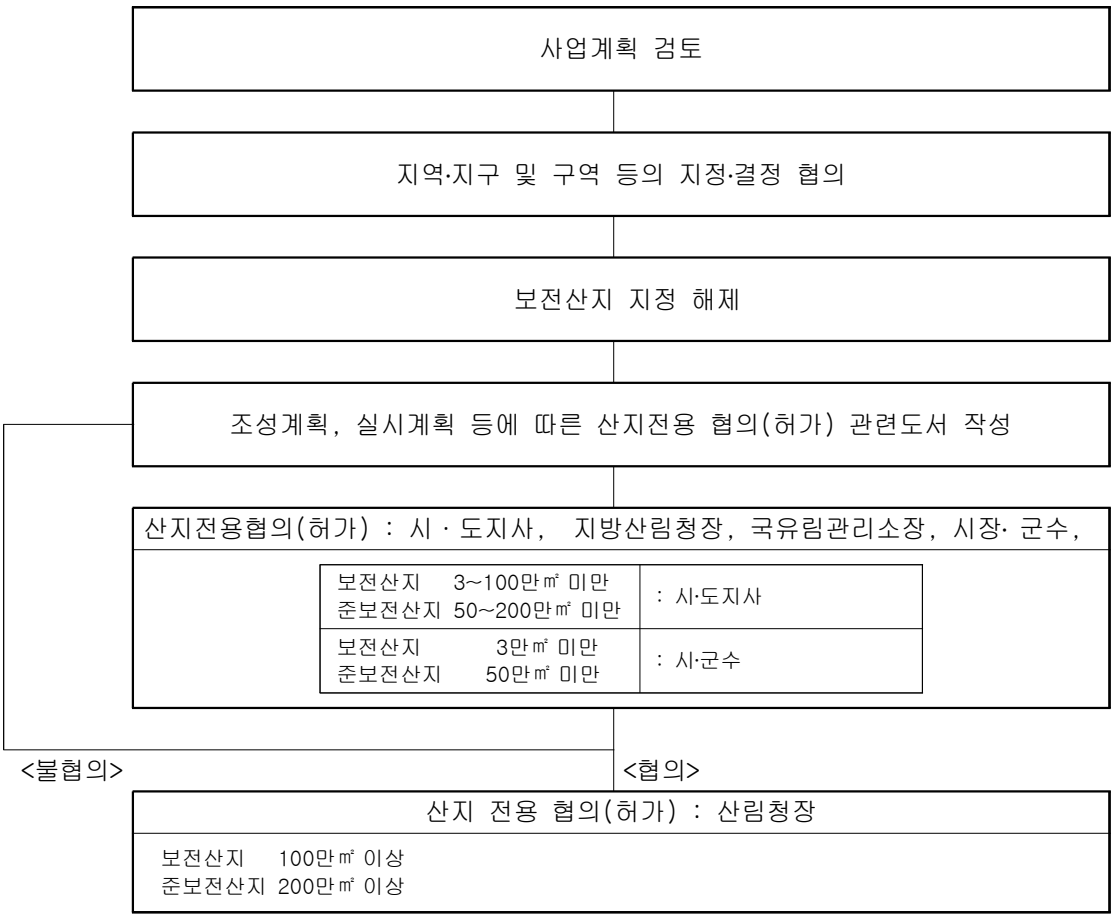

3-4 품 산정의 원단위 산정과 기준

3-4-1 표준품 산정내역

○ 표준품 산정의 기준이 되는 비목은 제1장 총칙에서 제시한 비목을 중심으로 하였으며, 산지전용업무에 필요한 사항만을 대상으로 한다.

○ 표준품 산정의 기본이 되는 직접인건비 품의 작업항목별 보할은 업무의 난이도를 감안하여 설정토록 한다.

종 별		내 용	세부항목	단위	비 고
직접비	직접인건비	1.계획안 검토	①관련법규 검토 ②관련계획 검토 ③주변지역과의 상관성검토	인·일 〃 〃	
		2.산지전용 협의 (허가)도서작성	①산지전용협의(허가)요청서 ②산지편입 현황조서 작성 ③피해방지계획서 작성 ④사업계획서 작성 ⑤산지관련 도서 작성	〃 〃 〃 〃 〃 〃	
		3.기술협의	①공청회 / 주민설명회 ②주민간담회 / 시민계획단 ③위원회 심의 지원 ④관계기관 협의	〃 〃 〃 〃	
	직접경비	여비, 인쇄비, 조감도, 회의준비비, 현장운영비 등		식	제1장 총칙참조
간접비	제경비	(직접인건비)×110%		〃	〃
	기술료	(직접인건비+제경비) ×20%		〃	〃

3-4-2 산정기준

1. 계획 · 기준면적 산정

○ 산지전용관련업무에 있어서의 원단위 설정을 위한 기준면적은 50만㎡로 선정한다.

○ 계획면적은 과업면적을 원칙으로 한다.

2. 표준품의 산정방법

○ 표준품의 적용에 있어 위 기준면적과 계획면적의 차이에 따른 산정은 아래의 수정식에 따라 기준면적의 소요작업량을 수정하여 산정한다.

○ 소요작업량 = 기준면적소요작업량 × 면적보정계수(α)

3. 계획안의 수정과 과업중지 등에 따른 산정방법

○ 계획안이 작성되고 주민의견, 의회보고 등 행정절차과정을 거쳐 계획안이 확정된 후 발주자의 사정에 의하여 계획안이 일부변경・재작업이 수행되는 경우에는 그 변경・재작업의 정도에 따라 엔지니어링사업대가의 50~100% 수준에서 비용을 추가 지급하여야 한다.

○ 과업수행 중 발주자의 사정에 따른 과업 중단으로 인해 정부 회계연도가 경과되어 현저한 비용의 차이가 발생하였을 경우에는 엔지니어링사업대가를 당해 신년도의 노임단가를 기준으로 재산정하여야 한다.

○ 산지전용협의와 산지전용허가가 별도로 이루어지는 경우에는 각각의 업무로 계상한다.

○ 지역·지구 및 구역 등의 지정·결정 협의는 별개의 업무로 계상한다.

○ 산지전용협의와 산지전용허가가 동시에 이루어지는 경우에는 단일업무로 계상한다.

○ 보전산지지정해제업무가 산지전용허가와 동시에 이루어지는 경우에는 단일업무로 계상한다.

3-4-3 단위별 변화수정과 보정

1. 면적의 대소에 대한 작업량보정계수 산정

○ 산지전용에 관한 업무 계획면적이 기준면적을 초과하거나 이에 못 미치는 경우의 직접인력 소요작업량의 산정을 위한 각 작업내용별 면적보정계수(α)는 다음과 같이 산정한다.

$$\alpha = \left(\frac{\text{계획면적}}{\text{기준면적}}\right)^{0.5} = \left(\frac{A}{50}\right)^{0.5}$$

α = 보정계수
A = 계획면적(만㎡)

계획단위 면적별 보정계수

계획면적(만㎡)	보정계수(α)	계획면적(만㎡)	보정계수(α)
10	0.447	70	1.183
20	0.632	100	1.414
30	0.775	150	1.732
40	0.894	200	2.000
50	1.000	300	2.449

주 : 계획면적이 10만㎡미만인 경우에는 계획면적 10만㎡를 기준으로 하여 산정한다.

2. 직접인건비 소요 작업량 산정

○ 계획면적의 대소에 따른 직접인력 소요작업량의 산정방법은 아래와 같이 기준면적의 직능별 직접인력 소요작업량에 계획단위 보정계수(α)를 곱하여 산출한다.

구 분	기준면적 (만㎡)	총작업량 (인 · 일)					
		기술사	특 급	고 급	중 급	초 급	보조원
산지전용	50	1.1α	4.2α	10.8α	15.7α	29.5α	34.1α

3-5 표준단위 업무분류와 원단위

기술업무의 직능별 직접인력에 의한 소요작업량 (50만㎡ 기준)

(단위 : 인·일/표준단위)

구 분	업무내용	표준단위	소요인력						비고
			기술사	특급	고급	중급	초급	보조원	
1.계획안검토	①관련법규 검토	50만㎡	0.1	0.2	0.3	0.5	0.9	1.0	
	②관련계획 검토	50만㎡	0.1	0.2	0.3	0.5	0.9	1.0	
	③주변지역과의 상관성 검토	50만㎡	0.1	0.2	0.5	0.7	1.2	1.5	
	소 계		0.3	0.6	1.1	1.7	3.0	3.5	
2. 산지전용 도서작성	①산지전용협의(허가)요청서	50만㎡	0.4	0.7	1.4	2.0	3.8	4.3	
	②산지편입 현황조서 작성	50만㎡	-	0.8	4.1	6.0	11.3	13.0	
	③피해방지계획서 작성	50만㎡	0.4	0.7	1.4	2.0	3.8	4.3	
	④사업계획서 작성	50만㎡	-	0.7	1.4	2.0	3.8	4.5	
	⑤산지관련 도서 작성	50만㎡	-	0.7	1.4	2.0	3.8	4.5	
	소 계		0.8	3.6	9.7	14.0	26.5	30.6	
총 계			1.1	4.2	10.8	15.7	29.5	34.1	
3.기술협의	①공청회/주민설명회	1식	2.0	2.0	2.0	4.0	4.0	4.0	주1
	②주민간담회/시민계획단	1식	2.0	2.0	2.0	4.0	4.0	4.0	
	③위원회심의 지원	1식	2.0	2.0	2.0	4.0	4.0	4.0	
	④관계기관 협의	1식	2.0	2.0	2.0	4.0	4.0	4.0	
	소 계		8.0	8.0	8.0	16.0	16.0	16.0	

주 : ①기술협의는 2회 이내 기준이며, 횟수가 늘어날 경우 증가배수에 해당하는 작업품과 비용을 가산한다. (필요항목 선택적 적용)

3-6 주요업무내용

구 분	업무내용	내 용
1. 계획안검토	①관련법규 검토	· 산지전용에 필요한 관계법 검토
	②관련계획 검토	· 산지전용과 관련된 상위 및 관련계획검토
	③주변지역과의 상관성 검토	· 당해 지역과 주변지역 관련사항
2. 산지전용 도서 작성	①산지전용협의 요청서	· 산지전용협의 요청서 작성
	②산지편입 현황조서 작성	· 시가화지역 또는 도시·군계획시설 부지로 변경되는 지역의 산지 지목별 토지조서 작성
	③피해방지계획서 작성	· 피해방지계획, 토사처리계획 등 작성
	④사업계획서 작성	· 도시·군기본계획 또는 도시·군관리계획안 · 용도지역 현황조서 · 인구밀도 현황조서
	⑤산지 관련 도서 작성	· 산지전용예정지 실측도 등 산지전용 협의도 작성 · 복구계획서 작성 · 농지원본 사본 작성

3-7 표준성과품

성과 구분	표준성과도서			비 고
	구 분	규 격	제출부수	
산지 전용 도서	1.사업계획서 및 산지전용협의 요청서 2.편입토지 및 현황계획조서 3.산지전용 협의도 4.피해방지계획서, 복구계획서	1식 1/5,000~1/25,000	3부 3부 3부 3부	계획안 요약 도시계획관련, 산지 도시계획관련, 산지

주 : 제출부수 및 성과품 종류가 증가할 경우에는 증가배수에 해당하는 작업품과 비용을 가산한다.

제4절 총괄계획관리(PPM : Project Planning Management)

4-1 정 의

○ 도시계획수립과 각종 개발사업에서 합리적이고 효율적인 계획이 수립되도록 계획과정에 수반되는 업무의 전과정과 이와 연관되는 각종 관련업무를 총괄 관리하는 것을 말한다.

○ 계획의 업무를 수립하는 과정에서 필요한 각종 요구사항을 충족시키는데 필요한 지식, 기량, 도구 및 기법 등을 업무활동에 적용하는 제반활동을 말하며, 이는 관리를 위한 전문적인 프로세스를 가지고 업무에 적용함을 의미한다.

○ 프로세스는 계획업무의 목표인 합리적이고 효율적인 계획수립을 위하여 수행하는 상호 연관된 일련의 조치 및 활동을 의미하며 착수, 기획, 실행, 종료로 구분되는 계획업무의 생애주기(Life Cycle)를 대상으로 한다.

○ 개발프로젝트의 기획, 발주, 설계, 시공, 유지관리 단계에 이르기까지 프로젝트를 종합관리하는 것으로 기획단계의 사업타당성 검토 결과를 기반으로 하여 프로젝트의 최적개발 방향을 제시와 마케팅, 파이낸싱, 설계, 분양, 시공단계에 이르는 개발프로젝트의 총괄계획관리를 말한다.

4-2 자료제공의 전제

○ 총괄계획관리(PPM)에 필요한 모든 관련자료는 원칙적으로 발주자가 제공하는 것으로 하되, 발주자가 제공하지 않는 자료는 과업을 수행하는 엔지니어링사업자가 수집한다.

4-3 업무범위와 추진과정

4-3-1 업무범위

○ 총괄계획관리의 업무대상은 도시계획 전 분야에 대하여 단일프로젝트 또는 종합프로젝트에 대한 계획 전과정에 대한 관리업무를 범위로 한다.

○ 총괄계획관리는 계획수립의 목적달성을 위해 다음의 내용에 따라 관리업무를 수행한다.

- 통합관리 : 여러개의 프로세스와 계획업무관리 활동을 식별하고 정의, 결합, 통합 및 조정하는 프로세스와 활동으로 계획업무의 단계별 공종별 업무를 분류하고 관리한다.

- 시간관리 : 계획업무를 목표한 시한내 적시에 완료할 수 있도록 필요한 프로세스로 관련법령에 따른 계획의 특성에 따라 공정을 관리하고 부진공정의 만회 대책을 마련한다.
- 품질관리 : 계획업무에 대한 과업지시서 등에서 제시한 목표에 따라 적합한 품질의 목표를 설정하고 최상의 성과품을 작성할 수 있도록 품질의 방침, 목표, 책임사항 등 제반사항을 관리한다.
- 의사소통관리 : 과업수행에 필요한 인적자원을 관리하고, 과업의 이해관계자에 대한 정보를 시의 적절하게 생성, 수집, 배포, 보관, 검색 및 최종적으로 처분하는데 필요한 업무를 수행한다.

4-3-2 추진과정

○ 타부처(관계기관)와 협의나 전문가 자문 등에 소요되는 기간은 과업수행기간에서 제외하여 그 소요기간만큼 과업수행기간을 연장하여야 한다.

계획총괄관리업무 추진과정

착수단계	·요구사항 분석, 이해관계자 식별, 역할 및 책임 정의, 지침 및 규정파악, 업무범위설정 등
계획단계	·업무분류 및 관리, 이해관계자 식별 및 관리, 업무목적 및 관리도구, 적용 표준평가 등
실행 & 통제 단계	·통제 프로세스, 품질 보증 표준, 리스크관리, 성과측정·분석, 보고·회의, 이해관계자 관리 등
종료단계	·종료 프로세스, 인수 프로세스, 고객요구사항, 교훈식별, 데이터 관리 등

4-4 품 산정의 원단위 산정과 기준

4-4-1 산정기준

○ 표준품 산정시 적용되는 제경비 및 기술료는 적용요율(α)에 포함하고 기타 필요한 직접비는 발주자 또는 계획·설계 엔지니어링사업자가 부담한다.

○ 표준품 산정의 기준은 계획·설계비에 대한 요율을 기준으로 하며, 기본계획 부문과 실시계획 부문으로 구분한다.

○ 표준품 산정기준의 기준이 되는 계획설계비(기준금액)는 10억단위로 하며, 최소과업의 기준 계획설계비는 5억원을 기준으로 한다.

○ $\alpha = (\frac{\text{계획금액}}{\text{기준금액}})^{-0.2} \times 10 = (\frac{A}{10\text{억원}})^{-0.2} \times 10$

4-5 표준단위 업무분류와 원단위

○ 용역비 산정을 위한 업무단위는 기본계획 부분과 실시설계 부문으로 구분

○ 관리대상 사업 용역비(계획 및 설계비) 대비 일정 요율 적용

(단위 : 금액/표준단위)

계획설계비 (억원)	표준 단위	계(%)	기본계획(%)	실시계획(%)	비 고
5	10억	11.490	4.596	6.894	제경비, 기술료 포함
10	10억	10.000	4.000	6.000	
20	10억	8.710	3.484	5.226	
30	10억	8.030	3.212	4.818	
50	10억	7.250	2.900	4.350	
70	10억	6.780	2.712	4.068	
100	10억	6.310	2.524	3.786	

4-6 주요업무내용

구 분	업무내용
1.통합관리	·과업의 전반적 진행을 통합관리하기 위한 단계별 공종별 업무파악 ·업무범위 결정을 위한 세부적인 업무분류체계(WBS) 수립 ·계획의 범위에 따라 계약조건의 결정 및 계약서 작성 ·과업수행을 위해 필요한 전문기관을 선정하고 계약체결 지원 ·과업내용의 정확한 전달을 위해 과업수행을 위한 과업지시서 작성
2.시간관리	·관련법률 및 계획의 특성에 따라 적절한 공정관리요소 도출 ·공종별로 요구되는 선행작업과 후행작업의 관계를 고려하여 공정계획 작성 ·과업지시서의 공정계획에 따른 진도관리 및 부진공정 만회대책 수립
3.품질관리	·과업지시서에 제시된 계획목표에 따라 적합한 품질목표 및 전략 작성 ·품질의 통제를 위한 계획수립 단계별 체크리스트 작성 ·체크리스트에 따른 지속적인 품질관리 및 과업완료 후 성과품 평가
4.의사소통관리	·과업수행에 필요한 인적자원을 수급하고 과업수행조직을 구성 ·이해관계자에 대한 업무와 참여범위를 결정하고 의사소통 계획을 수립 ·민원, 클레임 등 갈등 발생시 의사소통 계획에 따라 분쟁 조정·해결 ·과업에 필요한 사업 정보를 적절하게 조달하고 분류체계를 작성하여 관리

4-7 표준성과품

성과구분	표준성과도서			비 고
	구 분	규 격	제출부수	
보고서	·공정보고서(월간, 주간) ·성과품 평가 보고서	발주자와 협의결정	1부	
관련문서	·프로젝트 관련 각종회의자료 ·각종 공문관련자료	발주자와 협의 결정	1부 1부	
기타자료		발주자와 협의결정	발주자와 협의결정	

주 : ①제출부수 및 성과품 종류가 증가할 경우에는 증가배수에 해당하는 작업품과 비용을 가산한다.
②계획보고서 및 기타 관련자료의 규격 및 제출부수는 발주자와의 협의에 의하여 비용을 산정한다.

제5절 계획관리

5-1 정 의

○ 계획관리라 함은 당초 수립된 계획내용과 적합하게 설계 또는 공사가 이루어 질 수 있도록 관리 · 감독하는 것을 말한다.

5-2 자료제공의 전제

○ 계획관리에 관한 업무에 필요한 모든 관련자료는 원칙적으로 발주자가 제공하는 것으로 하되, 발주자가 보유하지 않는 자료는 엔지니어링사업자가 수집한다.

○ 발주자가 제공하지 못하는 자료의 조사에 있어서는 그 규모·내용에 의거하여 별도의 엔지니어링사업대가를 산정하여 엔지니어링사업자가 수행하며, 관련자료의 기밀성과 광범위한 자료가 필요한 경우 조사·분석에 필요한 상당기간과 자료수집비용이 전제되어야 한다.

5-3 업무범위와 추진과정

5-3-1 업무범위

○ 계획관리업무의 범위는 당초 수립된 계획내용과 적합하게 조사·설계·공사가 이루어 질 수 있도록 관리·감독하고 지도하는 엔지니어링활동 업무로 한다

5-3-2 추진과정

○ 타부처(관계기관)와 협의나 전문가 자문 등에 소요되는 기간은 과업수행기간에서 제외하여 그 소요기간만큼 과업수행기간을 연장하여야 한다.

계획관리 추진과정

자료 수집 및 현장 조사
↓
당초 계획내용 검토 관련계획 및 기준(지침, 법규 등) 검토
↓
당초 계획내용과 설계·시공 내용의 부합성 검토
↓
당초 계획내용의 이행에 대한 관리·감독, 대안 제시 및 기술자문·지도
↓
계획관리 결과보고서 작성 및 감리완료 통보

5-4 품 산정의 원단위 산정과 기준

5-4-1 산정 기준

○ 표준품 산정시 적용되는 제경비 및 기술료는 산정금액 포함하고, 기타 필요한 직접비는 발주자 또는 계획·설계 엔지니어링사업자가 부담한다.

○ 표준품 산정의 기준은 공사비에 대한 요율을 기준으로 하며, 기본설계 부문과 실시설계 부문으로 구분한다.

○ 표준품 산정기준의 기준이 되는 계획관리비는 공사비 50억단위로 하며, 최소과업의 기준 계획관리비의 공사비는 50억원을 기준으로 한다.

○ $\alpha = (\frac{\text{계획금액}}{\text{기준금액}})^{-0.2} \times 0.1 = (\frac{A}{50\text{억원}})^{-0.2} \times 0.1$

5-5 표준단위 업무분류와 원단위

○ 용역비 산정을 위한 업무단위는 기본설계 부문과 실시설계 부문으로 구분

○ 관리대상 사업 용역비(계획 및 설계비) 대비 일정 요율 적용

(단위 : 금액/표준단위)

공사비(억원)	표준 단위	계(%)	기본설계(%)	실시설계(%)	비 고
50	50억원	0.100	0.040	0.060	제경비, 기술료 포함
100	50억원	0.087	0.035	0.052	
200	50억원	0.076	0.030	0.045	
300	50억원	0.070	0.028	0.042	
400	50억원	0.066	0.026	0.040	
500	50억원	0.063	0.025	0.038	
700	50억원	0.059	0.024	0.035	
1,000	50억원	0.055	0.022	0.033	
1,500	50억원	0.051	0.020	0.030	
2,000	50억원	0.048	0.019	0.029	
3,000	50억원	0.044	0.018	0.026	
5,000	50억원	0.040	0.016	0.024	
7,000	50억원	0.037	0.015	0.022	
10,000	50억원	0.035	0.014	0.021	

주 : 건설기술관리법(국토교통부 2012-444호)의 설계감리 대가기준 요율 방식 적용

참고 : (설계감리 기준의 10% 준용)

5-6 주요업무내용

구 분	업무내용
1.자료 수집 및 현장조사	·대상계획의 관련자료 수집 ·현장조사
2.당초 계획내용 등 검토	·수립중이거나 수립 완료된 계획내용 검토 ·관련계획 및 기준(지침, 법규등) 검토
3.계획이행에 대한 관리·감독과 적정성 검토 및 대안작성	·당초 계획내용의 이행에 대한 관리·감독 ·당초 계획내용에 따른 설계내용의 적정성, 부합성 검토 ·대안 제시 및 기술자문
4.성과품 작성	·계획관리 결과보고서의 작성

5-7 표준성과품

성과구분	표준성과도서			비 고
	구 분	규 격	제출부수	
보고서	·계획관리 결과보고서	발주자와 협의결정	1부	
관련문서	·대상계획의 관련 자료 ·현장 조사 자료 ·대안 제시 및 기술자문 자료 ·각종 공문관련자료	발주자와 협의 결정	1부 〃	
기타자료		발주자와 협의결정	발주자와 협의결정	

주 : ①제출부수 및 성과품 종류가 증가할 경우에는 증가배수에 해당하는 작업품과 비용을 가산한다.
②계획관리보고서 및 기타 관련자료의 규격 및 제출부수는 발주자와의 협의에 의하여 비용을 산정한다.

제6절 사후관리계획

6-1 정 의

○ 사후관리계획이라 함은 각종 개발사업에 있어서 계획/설계 업무의 준공이후부터 개발사업의 공사시행 중 사업여건 변화 및 공사여건의 변화에 따라 계획(기본계획 및 실시계획, 지구단위계획 등), 기본설계, 실시설계 등의 변경사항을 검토 반영하여 관련 인허가를 득하는 것을 말한다.

6-2 자료제공의 전제

○ 사후관리계획에 관한 업무에 필요한 모든 관련자료는 원칙적으로 발주자가 제공하는 것으로 하되, 발주자가 보유하지 않는 자료는 엔지니어링활동주체가 수집한다.

○ 발주자가 제공하지 못하는 자료의 조사에 있어서는 그 규모·내용에 의거하여 별도의 엔지니어링사업대가를 산정하여 엔지니어링활동주체가 수행하며, 관련자료의 기밀성과 광범위한 자료가 필요한 경우 조사·분석에 필요한 상당기간과 자료수집비용이 전제되어야 한다.

6-3 업무범위와 추진과정

6-3-1 업무범위

○ 사후관리계획의 업무범위는 기본계획, 기본설계, 실시설계 등을 엔지니어링 활동의 주 범위로 한다.

○ 타부처(관계기관)와 협의나 전문가 자문 등에 소요되는 기간은 과업수행기간에서 제외하여 그 소요기간만큼 과업수행기간을 연장하여야 한다.

6-3-2 추진과정

○ 타부처(관계기관)와 협의나 전문가 자문 등에 소요되는 기간은 과업수행기간에서 제외하여 그 소요기간만큼 과업수행기간을 연장하여야 한다.

사후관리계획 추진과정

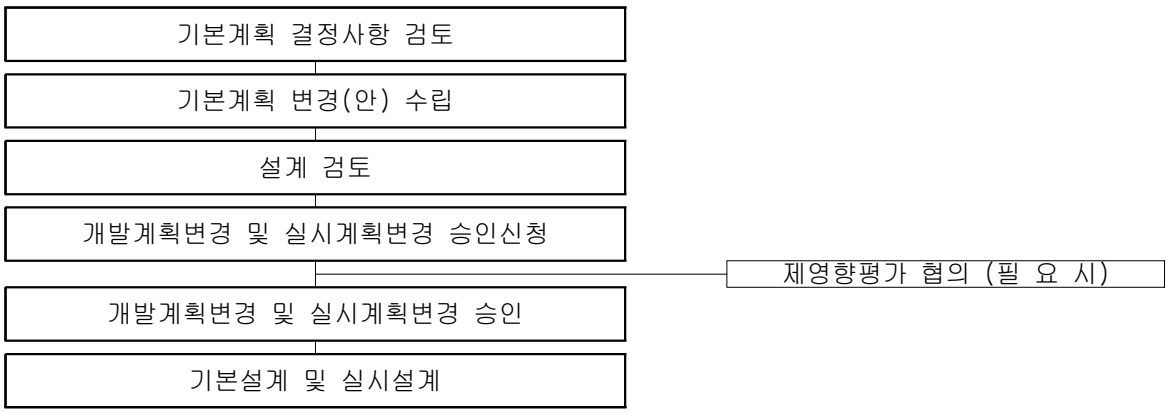

6-4 품 산정의 원단위 산정과 기준

6-4-1 표준품 산정내역

○ 표준품 산정의 기준이 되는 비목은 제1장 총칙에서 제시한 비목을 중심으로 하였으며, 계획관리에 관한 업무에 필요한 사항만을 대상으로 한다.

○ 표준품 산정의 기본이 되는 직접인건비 품의 작업항목별 보할은 업무의 난이도를 감안하여 설정토록 한다.

종 별		내 용	세부항목	단위	비 고
직접비	직접인건비	1.기본계획 변경	①기존계획검토 ②주택계획 ③토지이용계획 ④교통계획 ⑤공급처리시설계획	인·일 〃 〃 〃 〃	
		2.지구단위계획변경	①용도지역·지구 ②가구 및 획지 ③건축물	〃 〃 〃	
		3.성과품작성	①인·허가 승인도서 작성 ②관련도서 작성	〃 〃	
		4.기술협의	①위원회 심의 지원 ②관계기관 협의	〃 〃	
		5.조사측량	측량품 별도적용		
		6.토질조사 및 시험	토질조사 및 시험품 별도적용		
		7.기본설계 및 실시설계	엔지니어링사업대가의 기준 중 건설부문공사비 요율을 적용		
	직접경비	여비, 인쇄비, 조감도, 회의준비비, 현장운영비 등		식	제1장 총칙참조
간접비	제경비	(직접인건비)×120%		〃	〃
	기술료	(직접인건비+제경비) ×30%		〃	〃

주 : 사후관리계획에 관련되는 부수적인 업무인 조사측량, 토질조사 및 시험, 각종영향성검토 및 각종영향평가업무는 별도의 엔지니어링활동업무로 계상한다.

6-4-2 산정기준

1. 계획·기준면적 선정

○ 기준면적은 50만㎡로 하였으며, 직능별 직접인력 소요원단위는 주택단지계획 등의 투입기술자 비율을 감안하여 설정하였다.

○ 계획면적은 변경이 수반되는 면적을 원칙으로 한다.

2. 표준품의 산정방법

○ 표준품의 적용에 있어 위 기준면적과 계획면적의 차이에 따른 산정은 아래의 수정식에 따라 기준면적의 소요작업량을 수정하여 산정한다.

○ 소요작업량 = 기준면적소요작업량 × 면적보정계수(α)

6-4-3 단위별 변화수정과 보정

1. 면적의 대소에 대한 작업량 보정계수 산정

○ 계획면적이 기준면적을 초과하거나 못 미치는 경우의 직접인력 소요작업량의 산정을 위한 면적보정계수(α)는 다음의 식에 의해 산정한다.

$$\alpha = \left(\frac{\text{계획면적}}{\text{기준면적}}\right)^{0.6} = \left(\frac{A}{50}\right)^{0.6}$$

α = 면적보정계수
A = 계획면적(만㎡)

계획단위 면적별 보정계수

계획면적(만㎡)	보정계수(α)	계획면적(만㎡)	보정계수(α)
3	0.184	70.0	1.224
5	0.251	100.0	1.516
10	0.381	150.0	1.933
30	0.736	200.0	2.297
50	1.000	300.0	2.930

주 : 계획면적이 3만㎡미만인 경우에는 계획면적 3만㎡를 기준으로 하여 산정한다.

2. 직접인건비 소요 작업량 산정

○ 계획면적의 대소에 따른 직접인력 소요작업량의 산정방법은 아래와 같이 기준면적의 직능별 직접인력 소요작업량에 계획단위 보정계수(α)를 곱하여 산출한다.

구 분	기준면적 (만㎡)	총작업량(인·일)					
		기술사	특 급	고 급	중 급	초 급	보조원
기본계획	50	12.8α	16.4α	52.9α	57.4α	143.2α	167.5α

6-5 표준단위 업무분류와 원단위

6-5-1 기본계획

기술업무의 직능별 직접인력 소요작업량 (면적 50만㎡ 기준)

(단위 : 인·일/표준단위)

구 분	업무내용	표준단위	소요인력						비고
			기술사	특급	고급	중급	초급	보조원	
1.기본계획 변경	①기존계획검토	50만㎡	0.9	2.7	5.1	7.3	7.3	10.9	
	②주택계획	50만㎡	0.7	1.1	5.3	5.3	8.8	13.2	
	③토지이용계획	50만㎡	1.5	1.6	9.0	9.8	32.5	32.5	
	④교통계획	50만㎡	1.0	0.6	4.8	4.8	14.5	19.8	
	⑤공급처리시설계획	50만㎡	1.3	1.6	7.4	7.4	14.9	14.9	
	소 계		5.4	7.6	31.6	34.6	78.0	91.3	
2.지구단위 계획변경	①용도지역·지구	50만㎡	0.9	1.3	3.5	1.8	11.1	12.6	
	②가구 및 획지	50만㎡	1.7	1.0	2.5	2.5	8.7	9.9	
	③건축물	50만㎡	3.3	4.6	10.0	12.9	26.6	29.5	
	소 계		5.9	6.9	16.0	17.2	46.4	52.0	
3.성과품 작성	①인·허가 승인도서 작성	50만㎡	1.2	0.8	2.7	2.7	8.8	10.3	
	②관련도서 작성	50만㎡	0.3	1.1	2.6	2.9	10.0	13.9	
	소 계		1.5	1.9	5.3	5.6	18.8	24.2	
총 계			12.8	16.4	52.9	57.4	143.2	167.5	
4.기술협의	①공청회/주민설명회	1식	2.0	2.0	2.0	4.0	4.0	4.0	주1
	②주민간담회/시민계획단	1식	2.0	2.0	2.0	4.0	4.0	4.0	
	③위원회심의 지원	1식	2.0	2.0	2.0	4.0	4.0	4.0	
	④관계기관 협의	1식	2.0	2.0	2.0	4.0	4.0	4.0	
	소 계		8.0	8.0	8.0	16.0	16.0	16.0	

주 : ①기술협의는 2회 이내 기준이며, 횟수가 늘어날 경우 증가배수에 해당하는 작업품과 비용을 가산한다. (필요항목 선택적 적용)

②각종영향성검토 및 각종영향평가업무는 별도의 엔지니어링활동업무로 계상한다.

6-5-2 조사측량

○ 측량품을 별도 적용한다.

6-5-3 토질조사 및 시험

○ 토질조사 및 시험품을 별도 적용한다.

6-5-4 기본설계 및 실시설계

○ 기본설계 및 실시설계의 산출기준은 엔지니어링사업대가의 기준 중 건설부문 공사비 요율을 적용한다.

6-6 주요업무내용

구 분	업무내용	내 용
1. 기본계획 변경	①기존계획 검토	·기존 기본계획검토 ·개발여건 변화 검토
	②주택계획	·주택호수밀도계획 ·유형별 주택계획 ·평형별 주택계획
	③토지이용계획	·기본방향설정 ·토지이용계획(대안)작성 및 비교 분석 ·공공시설용지계획
	④교통계획	·가로망의 기능 및 체계설정 ·간선가로망계획 ·세가로망계획
	⑤공급처리시설계획	·상수도계획 ·하수도 및 배수계획 ·통신계획
2. 지구단위 계획변경	①용도지역·지구	·용도지역·지구 세분
	②가구 및 획지	·기존 대지규모 및 용도지역지구에 적합한 가구 및 획지규모에 대한 계획 및 조정계획
	③건축물	·가구 및 획지조정계획에 따른 건축물 및 시설배치, 용도, 밀도, 높이, 형태, 색채 및 건축선에 대한 계획 ·대지안의 공지, 공개공지 등
3. 성과품작성	①인·허가 승인도서 작성	·인·허가 승인도서 작성
	②관련도서 작성	·각종검토서, 보고 및 협의자료 작성

6-7 표준성과품

성과부분	표준성과도서			비 고
	구 분	규 격	제출부수	
관련도서	·인·허가 승인도서	발주자와 협의결정	1식	
관련문서	·보고용 자료	발주자와 협의 결정	1부	
기타자료	·전산자료	발주자와 협의결정	1식	

주 : ①제출부수 및 성과품 종류가 증가할 경우에는 증가배수에 해당하는 작업품과 비용을 가산한다.
②계획보고서 및 기타 관련자료의 규격 및 제출부수는 발주자와의 협의에 의하여 비용을 산정한다.

제7절 도시계획 퍼실리테이션(Facilitation)

7-1 정 의

○ 도시의 미래, 기존 도시의 기능회복과 활성화를 위해 계획, 개발, 정비, 관리 등 주민의 다양하고 적극적인 참여가 필요, 이를 위해 도시계획직무에 전문가로 활동 중인 도시계획 퍼실리테이터가 적합하며 주민설명회, 주민간담회 등 기본적인 주민참여 활동은 물론 다양한 도시계획분야와 관련된 회의, 워크샵, 컨설팅 등에 참여 한다

○ 이러한 참여와 경청을 통해 도시계획분야와 관련된 고객의 정해진 목표를 달성하기 위하여 참가자의 지식, 경험 및 아이디어를 결집하고 상호토의, 관계자의 협력을 통하여 의사결정 및 합의를 도출하기 위한 조력자적인 회의진행과 프로세스의 촉진자 역할을 수행하는 것을 도시계획 퍼실리테이션이라 한다.

7-2 자료제공의 전제

○ 도시계획 퍼실리테이션 수행을 위한 모든 관련 자료는 발주자 및 고객이 제공한다.

7-3 업무범위와 추진과정

7-3-1 업무범위

1. 도시계획 퍼실리테이션 업무범위

○ 도시계획 퍼실리테이션의 업무범위는 도시계획 직무에서 발생할 수 있는 핵심과제 발굴, 도시발전 등 비전만들기, 아이디어도출, 다양한 의사결정과정을 촉진하여 합의 도출, 이해관계자의 갈등을 협력적 방식으로 해소, 그룹원의 활력증진 등의 역할을 통하여 협력적 공동작업이 이루어질 수 있도록 공정을 관리하고 원하는 목표를 효과적으로 달성하는 일이다.

2. 도시계획직무 참여범위

① 국토 및 지역계획 : 국토종합계획, 도종합계획, 지역계획, 농·산·어촌계획 등 직무로서 필요시 공청회, 주민설명회, 주민간담회, 주민설문조사, 관련회의, 워크샵 등 참여

② 도시계획 : 광역도시계획, 도시·군기본계획, 도시·군관리계획, 도시·군관리계획(재정비), 도시·군관리계획(변경)결정(단위), 도시(지역)교통계획, 지형도면고시계획, 단계별집행계획, 개발제한구역 관리계획, 도시계획 기초조사, 성장관리방안, 개발행위허가 등 직무로서 필요시 시민계획단, 공청회, 주민설명회, 주민간담회, 주민설문조사, 관련회의, 워크샵 등 참여

③ 도시설계 : 지구단위계획, 마을만들기 등 직무로서 필요시 시민계획단, 공청회, 주민설명회, 주민간담회, 주민설문조사, 관련회의, 워크샵 등 참여

④ 도시재생 : 도새재생계획, 도시재생전략계획, 도시재생활성화계획, 재정비촉진계획, 도시 및 주거환경정비 기본계획, 구역지정(정비계획), 주거환경개선사업, 주거환경관리사업, 가로주택정비사업, 사업시행계획, 관리처분계획 등 직무로서 필요시 시민계획단, 공청회, 주민설명회, 주민간담회, 주민설문조사, 관련회의, 워크샵 등 참여

⑤ 도시개발 : 환지방식 개발계획, 주택단지 개발계획, 산업단지 개발계획, 캠퍼스 계획, 유통(물류)단지 개발계획 등 직무로서 필요시 시민계획단, 공청회, 주민설명회, 주민간담회, 주민설문조사, 관련회의, 워크샵 등 참여

⑥ 도시경관 : 시・군경관계획, 도시・군경관부문계획, 개발사업경관계획, 경관상세계획, 농・산・어촌경관계획, 경관기본설계, 사회기반시설사업 경관심의, 건축물경관심의, 경관성검토 등 직무로서 필요시 시민계획단, 공청회, 주민설명회, 주민간담회, 주민설문조사, 관련회의, 워크샵 등 참여

7-3-2 추진과정

도시계획 퍼실리테이션 업무흐름

7-4 품 산정의 원단위 산정과 기준

7-4-1 표준품 산정내역

○ 표준품 산정의 기준이 되는 비목은 제1장 총칙에서 제시한 비목을 중심으로 하였으며, 개발사업타당성조사・분석업무에 필요한 사항만을 대상으로 한다.

○ 표준품 산정의 기본이 되는 직접인건비 품의 작업항목별 보할은 업무의 난이도를 감안하여 설정토록 한다.

종 별		내 용	세부항목	단 위	비 고
직접비	직접인건비	1.비전만들기	①조직배분 및 구성 ②목표정립 ③비전만들기	인·일 〃 〃	
		2.핵심과제도출	①이슈도출 ②SWOT분석 ③핵심과제 도출	〃 〃 〃	
		3.의사결정	①전략수립 ②아이디어 창출 ③문제해결방안 도출 ④갈등해결방안 도출	〃 〃 〃 〃	
		4.성과점검	①성과내용 반영여부 점검	〃	
	직접경비	여비, 인쇄비, 조감도, 회의준비비 현장운영비 등		식	제1장 총칙참조
간접비	제경비	(직접인건비)×120%		〃	〃
	기술료	(직접인건비+제경비) ×30%		〃	〃

7-4-2 산정 기준

1. 계획·기준회수산정

○ 도시계획 퍼실리테이션 업무의 원단위 설정을 위한 기준회수를 26회로 하고, 최소기준을 8회로 한다.

2. 표준품의 산정방법

○ 표준품의 적용에 있어 기준회수와 계획회수의 차이에 따른 품 산정을 아래의 수정식에 따라 기준횟수의 소요작업량을 수정하여 산정한다.

○ 소요작업량 = 기준회수 × 회수보정계수(α) × 작업량보정계수(β)

7-4-3 단위별 변화수정과 보정

1. 작업량 보정계수 산정

1) 계획회수에 따른 작업량 보정계수 산정

○ 도시계획 퍼실리테이션이 기준회수를 초과하거나 이에 못미치는 경우의 직접인력소요 작업량의 산정을 위한 각 작업내용별 보정계수(α)는 다음과 같이 산정한다.

$$\alpha = (\frac{\text{계획회수}}{\text{기준회수}})^{0.6} = (\frac{A}{26})^{0.6}$$

α : 보정계수
A : 계획회수(회)

2) 참여인원의 규모 변화에 대한 작업량 보정계수 산정

구 분	작업량 보정계수(β)
1. 참여인원 20인 기준	1.00
2. 참여인원 50인 기준(마을만들기 등 도시재생사업)	1.50
3. 참여인원 100인 기준(주민참여형 도시·군기본계획 등)	1.75

2. 직접인건비 소요 작업량 산정

○ 계획회수의 대소에 따른 직접인력 소요작업량의 산정방법은 아래와 같이 기준회수의 직능별 직접인력 소요작업량에 참여인원 규모보정계수(α, β)를 곱하여 산출한다.

구 분	기준회수 (회)	총 작 업 량 (인·일)					
		기술사	특 급	고 급	중 급	초 급	보조원
도시계획 퍼실리테이션	26	14.0αβ	14.0αβ	-	-	-	-

7-5 표준단위 업무분류와 원단위

기술업무의 직능별 직접인력 소요작업량(26회 기준)

(단위 : 인·일/표준단위)

구 분	업무내용	표준단위	소요인력						비고
			기술사	특급	고급	중급	초급	보조원	
1.비전만들기	①조직배분 및 구성 ②목표정립 ③비전만들기	26회 26회 26회	0.5 0.5 0.5	0.5 0.5 0.5	- - -	- - -	- - -	- - -	
2.핵심과제 도출	①이슈도출 ②SWOT분석 ③핵심과제 도출	26회 26회 26회	1.0 1.0 1.0	1.0 1.0 1.0	- - -	- - -	- - -	- - -	
3.의사결정	①전략수립 ②아이디어 창출 ③문제해결방안 도출 ④갈등해결방안 도출	26회 26회 26회 26회	1.5 2.0 2.0 2.0	1.5 2.0 2.0 2.0	- - - -	- - - -	- - - -	- - - -	
4.성과점검	①성과내용 반영여부 점검	26회	2.0	2.0	-	-	-	-	
계			14.0	14.0	-	-	-	-	

7-6 주요업무내용

구 분	업무내용
1.사전준비	·사전정보 파악, 구성원에 대한 질문 ·회의의 효과, 목적, 기대사항
2.비전만들기	·조직배분 및 구성 ·목표정립, 비전만들기, 초점맞추기
3.핵심과제 도출	·SWOT분석 및 분야별 이슈도출 ·핵심과제 도출
3.의사결정	·실행전략수립 및 전략실현을 위한 아이디어 창출 ·갈등해결방안 도출
4.성과점검	·회의결과 및 보완점 보고 ·성과내용 반영여부 점검

7-7 표준성과품

성과구분	표준성과도서			비 고
	구 분	규 격	제출부수	
보 고 서	·회차별보고서	발주자와 협의결정	2부	

주 : 제출부수 및 성과품 종류가 증가할 경우에는 증가배수에 해당하는 작업품과 비용을 가산한다.

국토계획 표준품셈 제정 및 개정경위

•1981.06.05~1982.05.14	: 한국기술용역협회 제정
•1982.05.15	: 과학기술처장관 승인요청
•1982.05.16~1982.07.22	: 건설부 및 국토개발연구원 검토의뢰(과학기술처)
•1982.07.22~1982.09.22	: 과학기술처 자체검토
•1982.09.23	: 검토결과의 보완지시(협회에 시달)
•1982.11.12	: 수정안 제출
•1982.11.24~1983.04.01	: 감사원,내무부,건설부,서울특별시,국토개발연구원, 재검토의뢰.
•1983.04.26	: 지역 및 도시계획 표준품셈 승인(과학기술처) (기관 622.1 ~ 4610, 1983. 4. 26)
•1983.06.04	: 승인에 대한 확인(기관 622.1 ~ 6284. 1983. 6. 4)
•1987.11.23	: 지역 및 도시계획 표준품셈과 조경 및 관광레저분야 통합 - 국토개발 표준품셈 개정추진 (제2차)
•1993.01.	: 국토개발 표준품셈 개정안 제출
•1993.02.17	: 관련기관 검토의뢰 (내무부, 건설부, 서울시, 한국도로공사, 한국토지개발공사, 대한주택공사, 국토개발연구원, 대한국토계획학회, 한국조경학회)
•1993.10.20	: 표준품셈심의위원회 심의
•1993.12.03	: 이사회의결
•1999.05.26	: 국토개발계획 표준품셈 개정 소위원회 구성 요청
•1999.05.	: 국토개발계획 표준품셈 개정(안) 검토의뢰 (건설교통부외 11개 관련기관)
•2000.11.15	: 표준품셈심의위원회 심의
•2000.12.11	: 이사회 의결
•2002.09.	: 국토개발계획 표준품셈 개정 추진
•2005.03.18	: 표준품셈 개정(안) 전문가 자문회의(지역 및 도시계획 분야)
•2005.03.29	: 표준품셈심의위원회 심의
•2005.08.04	: 표준품셈 개정(안) 전문가자문회의(조경 및 관광레저계획 분야)
•2007.06.15	: 표준품셈심의위원회 심의
•2007.11.09	: 이사회 의결
•2013.12.30	: 국토개발계획 표준품셈 개정연구 계약 (2013.12.30 ~ 2014.05.31)
•2014.05.20 ~ 2014.06.03	: 관련기관 검토의뢰 1차
•2014.05.28	: 공청회
•2014.08.29 ~ 2014.09.15	: 관련기관 검토의뢰 2차
•2014.09.30	: 기술표준위원회 심의
•2014.10.31.	: 이사회 의결
•2015.01.	: 국토개발계획 표준품셈 일부개정 추진
•2015.04.19	: 기술표준위원회 심의
•2015.07.	: 이사회 의결

◆ 본 표준품셈은 발주자 및 수주자가 도시계획 및 조경분야 엔지니어링사업 수행시 예정가격 산정 등 대가 산출에 따른 기초자료로 활용하도록 하기 위해 작성한 것입니다.

◆ 본 표준품셈의 일반적인 사항은「한국엔지니어링협회 기획협력실 법제팀 (Tel : 02-3019-3353) 또는 (사)한국도시계획기술사회 (Tel : 02-3446-1627, Fax : 02-581-0554, www.pupa.or.kr) 또는 (사)한국조경사회 (Tel : 02-565-1712, Fax : 02-565-1713, www.ksla.or.kr)」로 문의하여 주시기 바랍니다.

국토계획 표준품셈

2015년 07월 일 인 쇄
2015년 07월 일 발 행

발 행 인 : 이 재 완
발 행 처 : 한국엔지니어링협회
T E L : 02-3019-3200
F A X : 02-3019-3300
홈 페 이 지 : www.kenca.or.kr